Kriminalitätsbelastung in öffentlichen Räumen (Kriminalitätsatlas Berlin 2013)

Karten zur Kriminalitätsverteilung in Berlin

Impressum

Herausgeber
Der Polizeipräsident in Berlin
Platz der Luftbrücke 6
12101 Berlin
Telefon (030) 4664 – 909 140/909 142
Fax (030) 4664 – 909 196
E-Mail lkast14@polizei.berlin.de
Homepage http://www.polizei.berlin.de

Redaktionelle Bearbeitung
Landeskriminalamt Berlin
LKA St 14

Druck und Verarbeitung
ZSE IV MZ 4

Nachdruck und sonstige Vervielfältigungen - auch auszugsweise - nur mit Quellenangabe gestattet

Inhaltsverzeichnis

	Seite
Impressum	2
Vorwort	4
Technische Hinweise	5
Grundsätzliche Bewertungskriterien	7
Kurzkommentar	13
Einwohnerzahlen	16
Deliktische Übersichten	17
Straftaten -insgesamt-	17
Kiezbezogene Straftaten	30
Raub -insgesamt-	43
Straßenraub, Handtaschenraub	56
Körperverletzung -insgesamt-	69
Schwere und gefährliche Körperverletzung	82
Nachstellung, Nötigung, Freiheitsberaubung, Bedrohung	95
Diebstahl -insgesamt-	108
Diebstahl von Kraftwagen	121
Diebstahl an/aus Kraftfahrzeugen	134
Fahrraddiebstahl	147
Wohnraumeinbruch	160
Branddelikte -insgesamt-	173
Brandstiftung	186
Sachbeschädigung -insgesamt-	199
Sachbeschädigung durch Graffiti	212
Rauschgiftdelikte	225

Vorwort

Mit der vorliegenden vierten Ausgabe des Berichts „Kriminalitätsbelastung in öffentlichen Räumen (Kriminalitätsatlas) Berlin“ wird eine Zäsur hinsichtlich der betrachteten Regionen vorgenommen.
Wurde in den bisherigen Berichten die Kriminalität auf Basis der Berliner Ortsteile dargestellt, erfolgt mit dieser Ausgabe eine Umstellung auf Bezirksregionen, der mittleren Ebene einer dreistufigen neuen Raumhierarchie, den lebensweltlich orientierten Räumen (LOR).

Die lebensweltlich orientierten Räume sind eine per Senatsbeschluss aus dem Jahr 2006 geschaffene Regionalstruktur und verbindlich als neue räumliche Grundlage für Planung, Prognose und Beobachtung demografischer und sozialer Entwicklungen in Berlin festgelegt worden.
Kriterien für die Abgrenzung der lebensweltlich orientierten Räume waren unter anderem ähnliche Bau- oder Sozialstrukturen bzw. Milieubildung, Barriereorientierung (große Straßen und Verkehrstrassen sowie natürliche Barrieren), aber auch eine Begrenzung der Einwohnerzahl.
Der Vorteil der Bezirksregionen gegenüber den bisherigen Ortsteilen liegt unter anderem in deren höherer Homogenität. Differieren z. B. die Einwohnerzahlen der Ortsteile sehr stark zwischen 156.000 (Neukölln) und rund 500 (Malchow), beträgt die höchste Einwohnerzahl einer Bezirksregion dagegen rund 62.000 (Tempelhofer Vorstadt). Die kleinräumigere Darstellung insbesondere der Innenstadtbereiche ermöglicht zutreffendere statistische Aussagen, die von der größeren Gebietseinheit Ortsteil bislang verdeckt wurden.

Der überwiegende Teil regional erhobener Daten in der Berliner Verwaltung wird mittlerweile auf Basis der lebensweltlich orientierten Räume abgebildet.
Somit dient das Werk noch stärker als bisher einer ressortübergreifenden Regionalplanung in der öffentlichen Verwaltung. Die Frequenz der Fortschreibung in einem zweijährigen Turnus ist den Zwecken der Verwaltung angepasst und nicht auf die taktischen Belange der Polizei abgestellt.

Weiterhin werden die erfassten Fälle und die Häufigkeitszahlen zu 17 verschiedenen Straftaten(gruppen) für nunmehr 138 Bezirksregionen und 12 Verwaltungsbezirke über zwei Jahre mit den jeweiligen Veränderungen in absoluten Zahlen und prozentual ausgewiesen. Die Häufigkeitszahlen werden ihrer Ausprägung nach auf Ebene der Bezirke und der Bezirksregionen grafisch darstellt.

Technische Hinweise

Datenherkunft

Als Datenbasis dient die amtliche Polizeiliche Kriminalstatistik (PKS).

Deliktauswahl

Bei der Auswahl der dargestellten Delikte fanden insbesondere die nachfolgenden Faktoren Berücksichtigung:

- ✓ Delikte mit hinreichend exakter Tatorterfassung
  (z. B. ist Taschendiebstahl für eine Einzelbetrachtung ungeeignet, da hier der Tatort meist vom Geschädigten nicht genau bezeichnet werden kann)
- ✓ Delikte mit hinreichend großer Grunddatenmenge
- ✓ Konzentration auf öffentlich wahrnehmbare Delikte (insbesondere „Straßenkriminalität“)
- ✓ Vorrangige Auswahl präventabler Delikte

Anhand dieser Kriterien wurden folgende Delikte für die Darstellung ausgewählt:

- Straftaten -insgesamt-
- Raub
- Straßenraub, Handtaschenraub
- Körperverletzung -insgesamt-
- Schwere und gefährliche Körperverletzung
- Nachstellung, Nötigung, Freiheitsberaubung, Bedrohung,
- Diebstahl -insgesamt-
- Diebstahl von Kraftwagen
- Diebstahl an/aus Kraftfahrzeugen
- Fahrraddiebstahl
- Wohnraumeinbruch
- Branddelikte -insgesamt- (Brandstiftung und Sachbeschädigung durch Inbrandsetzen)
- Brandstiftung
- Sachbeschädigung -insgesamt-
- Sachbeschädigung durch Graffiti
- Rauschgiftdelikte

Kiezbezogene Straftaten

Neben den genannten Straftatengruppen, die so auch in der PKS ausgewiesenen werden, wurde zusätzlich die Summe der sogenannten „kiezbezogenen Straftaten“ gebildet.

Bei der Auswahl der Delikte, die Eingang in die „kiezbezogenen Straftaten“ fanden, wurden in erster Linie Aspekte wie

- ✓ eine hohe Wahrscheinlichkeit regionaler Bezüge (Wohnort der Tatverdächtigen),
- ✓ Fälle der häuslichen Gewalt mit den Delikten Körperverletzung, Nötigung und Bedrohung,
- ✓ Indikatoren von Verwahrlosungstendenzen (Destruktionsdelikte, Vandalismus) und
- ✓ eine erkennbare Nichtachtung staatlicher Autorität

berücksichtigt.
Tatgelegenheitsstrukturen (wie z. B. Ladendiebstahl in Einkaufsgegenden und „Schwarzfahren“ im Nahverkehr) haben daher bei dieser Betrachtungsebene nur wenig Einfluss auf die Kriminalitätsbelastung.

Die Summe der „kiezbezogenen Straftaten“ wird somit aus den folgenden Delikten gebildet:

- Automateneinbruch
- Bedrohung
- Freiheitsberaubung
- Keller- und Bodeneinbruch
- Körperverletzung / Körperverletzung in der Öffentlichkeit
- Misshandlung von Kindern / Schutzbefohlenen
- Nötigung
- Raub
- Sachbeschädigung an Kfz
- Widerstand gegen Vollstreckungsbeamte
- Wohnungseinbruch

Periodizität

Die Statistik wird alle 2 Jahre zum 31.12. erstellt.

Genauigkeit der regionalen Zuordnung

Die PKS-Daten enthalten als auswertbare Regionalangabe lediglich den Gemeindeschlüssel. Adressgenaue Regionalangaben und damit die Zuordnung zu den Bezirken und Bezirksregionen lassen sich nur durch Abgleich der PKS-Daten mit verlaufsstatistischen Informationen aus dem Vorgangsbearbeitungssystem der Polizei Berlin (POLIKS) erlangen. Gut 4% der gesamten PKS-Fälle werden auf elektronischem Weg von Polizeidienststellen anderer Bundesländer und - vor allem - von der Bundespolizei gemeldet. Für diese Fälle ist kein Abgleich mit dem Vorgangsbearbeitungssystem möglich. Über den elektronischen PKS-Datensatz wird mittlerweile wenigstens der Bezirk abgebildet, so dass auf Bezirksebene der Anteil der zuzuordnenden Fälle größer ist.

Die fehlende regionale Zuordnung ist lediglich bei der Sachbeschädigung durch Graffiti von besonderer Relevanz. Rund 16% der Fälle werden von der Bundespolizei bearbeitet, weil sie auf dem Gebiet der Deutschen Bahn bzw. der S-Bahn begangen werden. Diese Fälle fehlen in den Auswertungen auf Ebene der Bezirksregionen.

Begriffserläuterung

Häufigkeitszahl (HZ)
ist die Zahl der bekannt gewordenen Fälle insgesamt oder innerhalb einzelner Deliktsarten, errechnet auf 100.000 Einwohner und Einwohnerinnen (Stichtag ist der 30.06. des Berichtsjahrs). Sie drückt die durch die Kriminalität verursachte Gefährdung aus.

$$HZ = \frac{Straftaten \times 100.000}{Einwohnerzahl}$$

Die Einwohnerdaten für den vorliegenden Bericht sind die der melderechtlich registrierten Einwohner und Einwohnerinnen (Quelle: Amt für Statistik Berlin-Brandenburg), da nur diese regional kleinräumig vorliegen. Im Gegensatz dazu werden für die Häufigkeitszahlen des Berichts zur Polizeilichen Kriminalstatistik nach einer bundesweiten Vereinbarung die amtlichen Bevölkerungsdaten verwendet. Diese werden anhand der letzten Volkszählung fortgeschrieben und liegen nur für Berlin gesamt vor. Somit weichen die Häufigkeitszahlen des Kriminalitätsatlasses geringfügig von denen des PKS-Berichts ab.

Zeichenerklärung

- nichts vorhanden / keine Veränderung
() Aussagewert eingeschränkt
X bei einer Basiszahl unter 100 wird keine Steigerungsrate berechnet

Grundsätzliche Bewertungskriterien

Das Zahlenmaterial des vorliegenden Berichtes ist so umfangreich, dass der Versuch einer allumfassenden Betrachtung und Bewertung scheitert. Die vielfältigen Kombinationsmöglichkeiten der Parameter Delikt, Bezirksregion, Jahr, absolute Fall- bzw. Häufigkeitszahl und deren Entwicklungen eröffnen unüberschaubare Auswertungsmöglichkeiten. Eine Bewertung nach gleichen Kriterien für jede Bezirksregion würde einen enormen Arbeitsaufwand bedeuten, viele Doppelungen enthalten und eben nicht die Besonderheiten jeder Bezirksregion berücksichtigen und außerdem nicht jeder Betrachtungsweise gerecht werden. Das gleiche gilt für eine ebenfalls mögliche an den Delikten orientierte Bewertung.

Daher werden im Folgenden lediglich einige grundsätzlich zu beachtende Faktoren für die Bewertung der vorliegenden statistischen Daten erläutert.

Struktur der Berliner Bezirksregionen (mittlere Hierarchieebene der lebensweltlich orientierten Räume LOR)

Die lebensweltlich orientierten Räume (LOR) und damit auch die Bezirksregionen wurden 2006 gemeinsam zwischen den planenden Fachverwaltungen des Senats, den Bezirken und dem Amt für Statistik Berlin-Brandenburg auf der Grundlage der von der Jugendhilfe bereits definierten Sozialräume einheitlich abgestimmt. Ziel war die Abbildung lebensweltlicher Homogenität bei gleichzeitiger Wahrung einer Vergleichbarkeit der Planungsraumeinheiten.

Gleichwohl unterscheiden sich die 138 Berliner Bezirksregionen in einigen Faktoren deutlich: Ihre jeweilige Fläche liegt zwischen 0,71 km² der Bezirksregion Helmholtzplatz und 43,1 km² für Zehlendorf-Südwest. Obwohl angestrebt, beim Zuschnitt der Bezirksregionen gegenüber den Ortsteilen eine Angleichung auch hinsichtlich der Bevölkerungszahlen zu erreichen, gibt es aber gerade hier einen Ausreißer nach unten. Die Bezirksregion Forst Grunewald weist lediglich 71 Einwohner und Einwohnerinnen auf. Die Bevölkerungszahlen der anderen Bezirksregionen reichen von 3.300 in der Bezirksregion Rummelsburger Bucht bis zu knapp 62.000 in der Tempelhofer Vorstadt.
Die Bevölkerungsdichte ist in der Region Helmholtzplatz mit 30.000 Einwohnern/km² am größten und (den „Sonderfall“ Forst Grunewald auslassend) in der Bezirksregion Schmöckwitz/Karolinenhof/Rauchfangswerder mit 240 Einwohnern/km² am geringsten (alle genannten Zahlenwerte sind gerundet und haben den Stand 30.06.2013). Dazu kommen geografische Besonderheiten, wie die deutlich unterschiedlichen Anteile von Wald-, Grün- und Wasserflächen. Auf weitere Faktoren mit Einfluss auf die in der jeweiligen Bezirksregion registrierte Kriminalität, wie das Vorhandensein von Gewerbegebieten bzw. Freizeitangeboten, die touristische Attraktivität und die Sozialstruktur, wird weiter unten eingegangen.

Der Bezirk Reinickendorf hat es als einziger Verwaltungsbezirk leider verabsäumt den dortigen Bezirksregionen „sprechende“ Namen zu geben. Lediglich die Bezeichnungen für die Bezirksregionen „MV1“ und „MV2“ lassen einen Raumbezug (zum Märkischen Viertel) erahnen. Die Bezeichnungen aller weiteren Bezirksregionen - West 1 bis 5, Nord 1 und 2 sowie Ost 1 und 2 – geben allenfalls einen groben Hinweis auf die geografische Lage der Bezirksregion innerhalb des Bezirks. Das direkte Zuordnen einer Region aus seiner Bezeichnung (das es sich z. B. bei der Bezirksregion West 1 um Teile von Tegel handelt erschließt sich nicht) ist unmöglich.

Häufigkeitszahl

Das Kartenmaterial des vorliegenden Berichts visualisiert die Werte der Häufigkeitszahlen, nicht die der absoluten Fallzahlen.
Die Häufigkeitszahl (HZ) ist einer der bundesweit verbindlichen Kriminalitätsquotienten, die die Zahl der bekannt gewordenen Fälle auf 100.000 Einwohner und Einwohnerinnern bezieht (siehe auch Seite 7). Nur so wird ein Vergleich von Gebieten mit unterschiedlichen Einwohnerzahlen möglich.

Bei der Bewertung der Höhe der Häufigkeitszahl muss jedoch immer wieder ihre grundsätzliche Schwäche berücksichtigt werden: Durch den Bezug lediglich auf die in einer (Bezirks)-Region Wohnenden bleiben die sich zusätzlich dort aufhaltenden Personen wie Touristinnen

und Touristen, Geschäftsreisende, Pendelnde und nicht gemeldete Personen unberücksichtigt. Dieser Personenkreis kann sowohl Opfer als auch Straftäter bzw. Straftäterin werden. Daraus folgt, dass die Häufigkeitszahl für besonders attraktive Gebiete eigentlich niedriger wäre, wenn man die über die Einwohnerzahl hinausgehende Anzahl von Personen beziffern und in die Berechnung einbeziehen könnte. Das ist aber nicht möglich. Hohe Häufigkeitszahlen sind somit nicht automatisch ein Zeichen negativer Wohn- und Lebensqualität; sie können auch Ausdruck besonderer Lebendigkeit und Beliebtheit von Gebieten sein.

Wie der Bezug auf 100.000 Einwohnerinnen und Einwohner verdeutlicht, dient die Häufigkeitszahl eher dem Vergleich von Gebieten mit relativ vielen dort Wohnenden. So werden z. B. in der PKS des Bundes die Häufigkeitszahlen der Bundesländer und der Großstädte ab 100.000 Einwohnerinnen und Einwohnern dargestellt.

Keine der festgelegten Berliner Bezirksregionen erreicht für sich allein eine Einwohnerzahl von 100.000. Eine Hochrechnung auf 100.000 Einwohner und Einwohnerinnen ist dennoch zulässig, eine Bewertung der Häufigkeitszahl wird jedoch umso problematischer, je weniger dort Wohnende eine Bezirksregion aufweist. Am Beispiel der bevölkerungsärmsten Bezirksregion Forst Grunewald mit nur 71 Einwohnerinnen und Einwohnern wird dies besonders deutlich: Nur eine Straftat verändert die Häufigkeitszahl um den Wert 1.400. Dieser Wert würde bei einigen Delikten, wie Raub und Diebstahl von Kraftwagen, dem sieben- bis achtfachen Wert von Berlin gesamt entsprechen. Aus diesem Grund wurde auf die Angabe einer Häufigkeitszahl für die Bezirksregion Forst Grunewald durchgängig verzichtet.

Dieses Beispiel soll aufzeigen, dass die Häufigkeitszahl für sich alleine nicht uneingeschränkt zur Bewertung herangezogen werden sollte. Das gilt insbesondere für bevölkerungsschwache Bezirksregionen und für Delikte mit grundsätzlich geringen Fallzahlen.

Einflussfaktoren auf die Häufigkeitszahl

Die Ursachen für die unterschiedlichen regionalen Belastungen und deren Veränderungen sind nicht unmittelbar dem Bericht zu entnehmen. Diese sind zu vielfältig und zum größten Teil nicht von der Polizei alleine zu beeinflussen. Der Bericht zeigt den Bezug zwischen Tatgelegenheitsstruktur und Raumbezug der Kriminalität auf.
Im Folgenden werden einige bedeutende Faktoren, die die Anzahl der verübten Straftaten in einem regionalen Bereich beeinflussen, dargestellt. Sie sind zum überwiegenden Teil unabhängig von den Einwohnern und Einwohnerinnen zu betrachten und wirken sich somit auf die Höhe der Häufigkeitszahl aus.

<u>Touristische Attraktivität</u>
Berlin erfreut sich seit Jahren stetig steigender Beliebtheit bei in- und ausländischen Besuchern und Besucherinnen; im Jahr 2013 wurden gut 11 Millionen Gäste gezählt. Diese können während ihres Aufenthalts in Berlin sowohl Opfer als auch Täter bzw. Täterin von Straftaten werden. So stellen Touristinnen und Touristen insbesondere für Tatverdächtige zum Taschendiebstahl eine willkommene Opfergruppe dar. Bestimmte Orte innerhalb Berlins gehören zum „touristischen Pflichtprogramm“. Dazu zählen unter anderem das Brandenburger Tor, der Reichstag, das Kanzleramt, die Straße Unter den Linden, die Friedrichstraße, der

Alexanderplatz, der Fernsehturm und der Potsdamer Platz. Die touristischen Hauptziele konzentrieren sich in den Bezirksregionen Tiergarten Süd, Regierungsviertel und Alexanderplatz.

Einzelhandelsstrukturen

Ladendiebstahl, ein Delikt das zwar nicht separat im vorliegenden Bericht betrachtet wird, aber einen Anteil von ca. 15% am Diebstahl insgesamt und von knapp 7% an Straftaten insgesamt hat, kann nur dort begangen werden, wo es entsprechende Geschäfte gibt. Gerade in Einkaufszentren, aber auch in bestimmten Straßenzügen, konzentrieren sich die Tatgelegenheiten. Neben Ladendiebstählen werden dort auch viele Betrugshandlungen im Zusammenhang mit nichtbarer Bezahlung begangen. Zusätzlich entwickeln sich größere Einkaufszentren häufig zu Treffpunkten/Aufenthaltsorten von Jugendlichen und der „Trinkerszene". Bedeutende Einkaufszentren oder -zonen gibt es heutzutage zwar in vielen Bezirksregionen; aber wo diese fehlen bzw. nur spärlich vorhanden sind, ist die Häufigkeitszahl zum Diebstahl insgesamt sehr niedrig. Das trifft unter anderem auf Müggelheim, Buckow, Karow, Kaulsdorf und Mahlsdorf zu.

Veranstaltungsorte

Bestimmte Örtlichkeiten in Berlin werden regelmäßig als Veranstaltungsort für Messen, Sportveranstaltungen, Konzerte, Jahr- und Weihnachtsmärkte sowie weitere Festivitäten jeder Art genutzt. Zum Zeitpunkt der Veranstaltungen hält sich eine Vielzahl von Wohnortfremden in diesen Bereichen auf. Nicht selten wird im Rahmen der genannten Veranstaltungen übermäßig Alkohol konsumiert, was sich auf die Begehung von einigen Delikten, wie Körperverletzung und Sachbeschädigung, auswirkt. Bedeutende Veranstaltungsorte sind das Messegelände in der Bezirksregion Westend, das Olympiastadion in der Bezirksregion Heerstraße und vor allem der Bereich um die Straße des 17. Juni in der Bezirksregion Tiergarten Süd. Zur Verdeutlichung sei hier beispielhaft erwähnt, dass für das Jahr 2006, als zur Fußball-WM in Deutschland die Fanmeile an der Straße des 17. Juni stattfand, zu vielen der betrachteten Delikten die mit Abstand höchsten absoluten Fallzahlen im Verlauf der betrachteten Jahre für die Bezirksregion Tiergarten Süd registriert wurden. Zu den genannten Veranstaltungsorten kommen viele weitere, die in dieser Gesamtbetrachtung keine gesonderte Erwähnung finden können. Gerade die Innenstadt bietet aufgrund der dort vertretenen politischen und wirtschaftlichen Institutionen einen bevorzugten Raum für Demonstrationen jeder Art. Im Rahmen von Demonstrationen kommt es nicht selten zu der Begehung von Straftaten wie Sachbeschädigungen, Widerstand gegen Polizeivollzugsbeamte und Verstößen gegen das Versammlungsgesetz.

Freizeitangebote

Hierzu zählen Naherholungsgebiete mit ausgedehnten Grünflächen in Parks und Wäldern, Freibäder/Badestellen usw. ebenso wie Gebiete mit vielen und/oder großen Diskotheken, Klubs, Kneipen und Großkinos. In und in der Nähe von Naherholungsgebieten kommt es aufgrund der kalkulierbaren Abwesenheit der Eigentümerinnen und Eigentümer häufiger zu Fahrrad- und Kraftwagendiebstählen. In Gegenden mit Möglichkeiten der abendlichen bzw. nächtlichen Freizeitgestaltung werden vermehrt Körperverletzungen, Bedrohungen pp. verübt, wobei oftmals übermäßiger Alkoholkonsum eine Rolle spielt.

Öffentlicher Personennahverkehr (ÖPNV)

Große Umsteigebahnhöfe des öffentlichen Personennahverkehrs, wie beispielsweise die Bahnhöfe Friedrichstraße, Alexanderplatz und Ostkreuz, werden tagtäglich von tausenden

Personen frequentiert. Das häufig vorherrschende Gedränge wird gerne von Taschendiebinnen und Taschendieben zur Ausübung ihres kriminellen Tuns genutzt. Der Taschendiebstahl wird im vorliegenden Bericht zwar nicht gesondert ausgewertet, ist aber Bestandteil des Diebstahls insgesamt und der Straftaten insgesamt. Auch bei Fahrraddiebstählen und Rauschgiftdelikten ist der Anteil von im Bereich des ÖPNV begangenen Taten relativ hoch: Viele Personen nutzen das Fahrrad zur Anfahrt zum ÖPNV und stellen es dort für längere Zeit unbeaufsichtigt ab. Der ÖPNV bietet aufgrund der hohen Mobilität und Unübersichtlichkeit gute Tatgelegenheiten für den Rauschgifthandel.

Justizvollzugsanstalten

In Berlin gibt es mehrere große Justizvollzugsanstalten, in denen bereits straffällig gewordene Personen, die auch in der Haft nicht vor der Begehung weiterer Straftaten zurückschrecken, untergebracht sind. Besonders deutlich wird dies bei der größten geschlossenen Haftanstalt Deutschlands, der JVA Tegel in der Bezirksregion West 1. Anhand weiterführender Analysen wurde festgestellt, dass rund 11% aller Straftaten in der Bezirksregion West 1 in der JVA Tegel verübt werden; bei den Rauschgiftdelikten sind es sogar ca. 86%. Das führt dazu, dass West 1 bei den Rauschgiftdelikten die dritthöchste Häufigkeitszahl im Jahr 2013 aufweist. Weiterhin werden überproportional viele Körperverletzungen sowie Nötigungen, Bedrohungen pp. in der JVA Tegel begangen. Ein ähnliches Bild ergibt sich in der Bezirksregion Charlottenburg Nord mit den Justizvollzugsanstalten Charlottenburg und Plötzensee sowie der Jugendstrafanstalt Berlin.

Sozialstruktur

Neben den bisher beschriebenen Faktoren, die vor allem für die unterschiedlichen Tatgelegenheitsstrukturen verantwortlich sind, gibt es weitere vielfältige Ursachen für Kriminalität, die im vorliegenden Bericht nur kurz erwähnt werden können.

Eine besondere Rolle spielen ökonomische und soziale Rahmenbedingungen, die je nach Region innerhalb Berlins deutlich unterschiedlich sind. Einen guten Einblick ermöglicht das Monitoring Soziale Stadtentwicklung der Senatsverwaltung für Stadtentwicklung und Umwelt. Darin werden mehrere Indikatoren, die die soziale Lage in einem Quartier beschreiben, dargestellt. Die Indikatoren sind Daten zur Arbeitslosigkeit, zur Langzeitarbeitslosigkeit, zum Transferbezug und zur Kinderarmut sowie deren Veränderungen. Die umfangreichen Daten und kartografische Darstellungen sind dem Internet zu entnehmen (http://www.stadtentwicklung.berlin.de/planen/basisdatenstadtentwicklung/monitoring/index.shtml).

Weitere interessante Hinweise bieten die Daten der melderechtlich registrierten Einwohnerinnen und Einwohner im Land Berlin, die in den entsprechenden, halbjährlich erscheinenden, Berichten des Amtes für Statistik Berlin-Brandenburg dargelegt werden (http://www.statistik-berlin-brandenburg.de/). Darin werden die Einwohnerdaten, u. a. differenziert nach Alter und Wohnlage, räumlich kleinteilig dargestellt.

Absolute Fallzahlen der ausgewählten Delikte

Neben den Straftaten insgesamt und den kiezbezogenen Straftaten werden 15 weitere Delikte (siehe Seite 5) betrachtet. Die einzelnen Delikte weisen sehr unterschiedliche absolute Fallzahlen auf, was bei einer Interpretation der Daten ebenfalls zu beachten ist.

Die meisten Fälle werden zu Diebstahl insgesamt registriert. Die rund 226.000 Diebstähle im Jahr 2013 entsprechen 45,0% aller Straftaten. In den Vorjahren (seit 2006) war der Anteil geringer, aber nicht unter 37,7%. Somit beeinflussen Entwicklungen im Bereich des Diebstahls auch die Entwicklung der Straftaten insgesamt nicht unerheblich.
Die gemäß der Höhe der Fallzahlen unbedeutendste der 15 betrachteten Deliktsgruppen stellt die Brandstiftung dar. Die knapp 1.000 Fälle machen nur 0,2% der Straftaten insgesamt aus. Aufgrund dieser geringen Fallzahlen kommt es auch häufiger zu Verschiebungen der Bezirksregionen mit den hier höchsten Belastungen.
Weiterhin ist zu bedenken, dass die meisten der ausgewählten Delikte nicht nur bei den Straftaten insgesamt sondern auch bei anderen Deliktsgruppen mitgezählt werden. Als Beispiel seien hier die Körperverletzungen genannt. Sie gehen mit einem Anteil von 40,9% in die kiezbezogenen Straftaten ein. Regionale Schwerpunkte bzw. Entwicklungen im Bereich der Körperverletzungen insgesamt wirken sich somit auch auf die kiezbezogenen Straftaten aus.

Prozentuale Veränderungen

Grundsätzlich sind zwei Betrachtungsweisen von besonderem Interesse: Einerseits können die Bezirksregionen hinsichtlich der absoluten Fallzahlen bzw. Häufigkeitszahlen untereinander verglichen werden, andererseits sind die Entwicklungen dieser Werte im Vergleich zum Vorjahr für jede einzelne Bezirksregion eine wichtige Analysemöglichkeit. Um Entwicklungen, die auf zum Teil sehr unterschiedlichen Ausgangswerten der jeweiligen Bezirksregionen basieren, vergleichbar zu machen, werden prozentuale Veränderungen errechnet. Dabei ist zu beachten, dass ein geringer Ausgangswert zu deutlichen prozentualen Veränderungen führen kann, selbst wenn die Entwicklung der absoluten Zahlen niedrig ist. Daher gilt der Grundsatz, dass prozentuale Veränderungen bei Basiszahlen unter 100 mit der gebotenen Vorsicht zu interpretieren sind.

Bezirke

Eine Analyse und Bewertung der Daten auf Ebene der Bezirke wird nicht als sinnvoll erachtet. Die einzelnen Bezirke sind zu groß und in sich zu inhomogen, als dass tiefergehende Erklärungsansätze greifen würden. Als Beispiel sei hier Charlottenburg-Wilmersdorf erwähnt: Im Jahr 2013 ist er in seiner Gesamtheit mit einer Häufigkeitszahl von 16.061 der am drittstärksten belastete Bezirk zu Straftaten insgesamt. Die zu Charlottenburg-Wilmersdorf gehörenden Bezirksregionen weisen Häufigkeitszahlen zwischen 6.503 für Wiesbadener Straße und 59.896 für Kurfürstendamm auf. Kurfürstendamm ist damit die am zweitstärksten belastete Bezirksregion, Wiesbadener Straße belegt in diesem „Ranking“ Platz 120 von 138.

Stark belastete Bezirksregionen

Im vor zwei Jahren veröffentlichten Kriminalitätsatlas (mit den Daten für 2010 und 2011) wurden an dieser Stelle Ausführungen zu „stark belasteten Ortsteilen 2006 bis 2011“ gemacht. Möglich wurde dies, weil aus den bis dahin erstellten drei Ausgaben des Kriminalitätsatlasses gleichartige Daten für sechs Jahre vorlagen. Das nahmen wir zum Anlass, den zusätzlichen Bericht „Kriminalitätsatlas 2006 bis 2011 – ein deliktischer Kurzüberblick“ zu erstellen. Darin wurden regionale Schwerpunkte und auffällige Entwicklungen zu allen im Kriminalitätsatlas dargestellten Delikten erhoben und analysiert. Im genannten Bericht wurde dargelegt, dass der für die Erarbeitung geleistete enorm hohe Arbeitsaufwand vieler Dienststellen der Polizei Berlin nicht alle zwei Jahre zu erbringen ist. Darüber hinaus machen Betrachtungen von Entwicklungen bzw. Veränderungen regionaler Kriminalitätsbelastungen in der Regel erst über einen längeren Zeitraum Sinn. Durch die Umstellung der regionalen Bezugsgröße von Ortsteile auf nunmehr Bezirksregionen liegen vergleichbare Daten nur für zwei Jahre vor. Im Folgenden wird daher nur kurz auf stark belastete Bezirksregionen hingewiesen.

Unter Außerachtlassung der Bezirksregion Forst Grunewald (siehe Seite 9) wurde 2012 und 2013 die höchste Häufigkeitszahl zu Straftaten insgesamt mit rund 75.000 in der Bezirksregion **Regierungsviertel** festgestellt. Mit deutlichem Abstand folgt in beiden Jahren die Bezirksregion **Kurfürstendamm** (knapp 60.000) und danach, ebenfalls wieder mit großem Abstand, die Bezirksregionen **Tiergarten Süd** und **Alexanderplatz** (jeweils um die 40.000). Die sich dann anschließenden Bezirksregionen weisen Häufigkeitszahlen unter 25.000 auf.

Regierungsviertel und Alexanderplatz

Diese beiden Bezirksregionen bilden gemeinsam mit der Bezirksregion Brunnenstraße Süd den Ortsteil Mitte, der 2006 bis 2011 bei der Betrachtung nach Ortsteilen zu den am meisten belasteten Ortsteilen zählte. Die vor zwei Jahren zum Ortsteil Mitte dargelegten Erklärungsansätze gelten somit fort: Ein Großteil der touristischen Hauptziele liegt in den Bezirksregionen Regierungsviertel und Alexanderplatz; beispielhaft seien das Brandenburger Tor, der Boulevard Unter den Linden, der Hackesche Markt, der Gendarmenmarkt und der Fernsehturm erwähnt. Zusätzliche Tatgelegenheiten bieten die vielfältigen Einkaufsmöglichkeiten und zahlreiche Büro- und Gewerbeflächen. Auch das Angebot für die abendliche Freizeitgestaltung ist mit vielen Theatern und Lokalen sehr hoch. Die Bezirksregionen Regierungsviertel und Alexanderplatz sind von mehreren U- und S-Bahnlinien durchzogen, dazu kommen die großen Umsteigebahnhöfe Friedrichstraße und Alexanderplatz. Darüber hinaus ist das Regierungsviertel eine der Bezirksregionen mit den wenigsten Einwohnern und Einwohnerinnen (rund 9.300).

Kurfürstendamm

Die Bezirksregion Kurfürstendamm erstreckt sich in einem relativ schmalen Streifen nördlich und südlich der Straße Kurfürstendamm vom Adenauer Platz bis zum Bahnhof Zoologischer Garten und dem Breitscheidplatz (sogenannte „City West“). Sie ist gekennzeichnet durch zahlreiche Einkaufsmöglichkeiten, ist Anziehungspunkt für Touristen und Touristinnen und

bietet viele Restaurants bzw. Nachtlokale. Die Bezirksregion Kurfürstendamm befindet sich mit den dort gemeldeten rund 14.600 Einwohnern und Einwohnerinnen in der Rangfolge nach Bevölkerungszahl im unteren Viertel; wird darüber hinaus aber von vielen „Nichtansässigen“ aufgesucht.
Kurfürstendamm bildet mit fünf weiteren Bezirksregionen den Ortsteil Charlottenburg. Dieser nahm bei der bis zum Jahr 2011 vorgenommenen Betrachtung der regionalen Kriminalität nach Ortsteilen meist den vierten Platz bei der Höhe der Häufigkeitszahl zu Straftaten insgesamt ein, wobei vor allem Diebstähle und Körperverletzungen eine Rolle spielten. Durch die nunmehr kleinräumigere Betrachtung nach Bezirksregionen wird deutlich, dass die teilweise großen Häufigkeitszahlen des Ortsteils Charlottenburg hauptsächlich durch die Bezirksregion Kurfürstendamm verursacht wurden. Diese weist in nahezu allen betrachteten Delikten im Vergleich zu den anderen Bezirksregionen hohe Werte auf.

Tiergarten Süd

Die Bezirksregion Tiergarten Süd ist in ihrer räumlichen Ausdehnung nahezu deckungsgleich mit dem Ortsteil Tiergarten, der 2006 bis 2011 bei der Betrachtung nach Ortsteilen zu den am meisten belasteten Ortsteilen zählte. In der Bewertung der „kriminellen Belastung“ haben sich somit keine Änderungen ergeben: Tiergarten Süd liegt im Herzen Berlins und hat trotz dieser innerstädtischen Lage nur rund 13.000 Einwohner. Etwa die Hälfte der Fläche wird von der Park- und Grünanlage „Großer Tiergarten“ eingenommen. An der Straße des 17. Juni und rund um den Großen Stern finden jährlich zahlreiche Großveranstaltungen (u. a. Silvester-Party, Fashion Week, Christopher Street Day, Sportveranstaltungen und vor allem die Fanmeile anlässlich der Fußball-Welt- und Europameisterschaften) statt. Während dieser Events steigt der Alkohol- und Drogenkonsum, was zu Enthemmungen und einem erhöhten Aggressionspotential führt. Die unzähligen Gäste sind naturgemäß nicht in der Einwohnerzahl enthalten. Das gleiche gilt für die vielen Touristinnen und Touristen, die die zahlreichen Sehenswürdigkeiten, wie den Reichstag und das Bundeskanzleramt, Teile des Potsdamer Platzes und das Sony-Center, besuchen.

(Spandau Mitte)

Die Bezirksregion Spandau Mitte würde an dieser Stelle als „stark belastete Bezirksregion“ an sich keine Erwähnung finden, da sie in den Jahren 2012 und 2013 mit einer Häufigkeitszahl zu Straftaten insgesamt von rund 19.000 jeweils den 19. Platz im „Ranking“ der Bezirksregionen einnimmt. Dennoch wird sie im Folgenden näher betrachtet, um hervorzuheben, dass Vergleiche mit den vormals betrachteten Ortsteilen nur in Ausnahmefällen möglich sind, nämlich dann, wenn Ortsteil und Bezirksregion eine gleiche räumliche Ausdehnung haben (wie Ortsteil Tiergarten und Bezirksregion Tiergarten Süd, siehe vorstehend).
Der Ortsteil Spandau gehörte bei der Analyse nach dieser Räumlichkeit gemeinsam mit den Ortsteilen Tiergarten und Mitte zu den drei besonders stark belasteten Ortsteilen. Als Erklärungsansätze konnten das Einkaufscenter Spandauer Arkaden, die Altstadt Spandau mit vielen Geschäften und dem jährlich dort stattfindenden Weihnachtsmarkt, der Fernbahnhof Berlin-Spandau sowie die Endhaltestelle der U-Bahnlinie 7 mit dem großen Umsteigebereich in Busse erkannt werden. Darüber hinaus gehört die Spandauer Neustadt (ein Teil des Ortsteils Spandau) zu den Bereichen Berlins mit der höchsten Bevölkerungsdichte und eher

schlechten Wohnlagen. Die dort vorhandene ungünstige Sozialstruktur hat ebenfalls Einfluss auf die Anzahl der registrierten Straftaten.
Die Bezirksregion Spandau Mitte enthält zu großen Teilen Bereiche, die auch dem Ortsteil Spandau zuzurechnen sind. Von den beschriebenen Faktoren für die relativ hohe Kriminalitätsbelastung des Ortsteils Spandau liegen die Altstadt, die U-Bahn-Endhaltestelle und die Spandauer Neustadt in der Bezirksregion Spandau Mitte. Das Einkaufscenter Spandauer Arkaden und der Fernbahnhof liegen jedoch in der angrenzenden Bezirksregion Wilhelmstadt. Die günstigen Tatgelegenheitsstrukturen, die in einem Ortsteil konzentriert sind, verteilen sich auf zwei Bezirksregionen. Beim beschriebenen Beispiel ist noch interessant, dass sowohl der Ortsteil Spandau als auch die beiden Bezirksregionen Spandau Mitte und Wilhelmstadt je ca.35.000 Einwohner und Einwohnerinnen aufweisen. Vollständigkeitshalber sei noch erwähnt, dass für Wilhelmstadt die Häufigkeitszahl für Straftaten insgesamt für das Jahr 2013 knapp 17.000 beträgt.

Fazit

Die vorstehenden Ausführungen zu stark belasteten Bezirksregionen machen deutlich, dass die verantwortlichen Strukturen dieser Regionen nur in sehr beschränktem Maß polizeilichen Einflussmöglichkeiten unterliegen. Es ist zu vermuten, dass die genannten Bezirksregionen auch zukünftig zu den am stärksten belasteten zählen werden (außer Spandau Mitte).
Auf die im Kriminalitätsatlas 2011 erwähnten Ortsteile Neukölln und Wedding, die zu einem Teil der betrachteten Delikte in den Jahren 2006 bis 2011 immer wieder als eine der am stärksten belasteten Ortsteile festgestellt wurden, kann aufgrund der Umstellung auf Bezirksregionen als Raumbezug derzeit nicht näher eingegangen werden: Der Ortsteil Neukölln wird durch fünf Bezirksregionen vollständig abgebildet, der Ortsteil Wedding durch die gesamte Bezirksregion Parkviertel und Teilen von zwei weiteren Bezirksregionen. Eine tiefergehende Analyse ist aus Kapazitätsgründen nicht zu leisten und macht, wie schon erwähnt, bei nur zwei zu betrachtenden Jahren wenig Sinn.

Grafische Darstellung der Berliner Bezirksregionen nach ihren Einwohnerzahlen

Der folgenden Seite ist eine grafische Darstellung der Berliner Bezirksregionen nach der Zahl ihrer melderechtlich registrierten Einwohner und Einwohnerinnen am Ort der Hauptwohnung zum Stichtag 30.06.2013 zu entnehmen. Die Daten wurden vom Amt für Statistik Berlin-Brandenburg zur Verfügung gestellt.

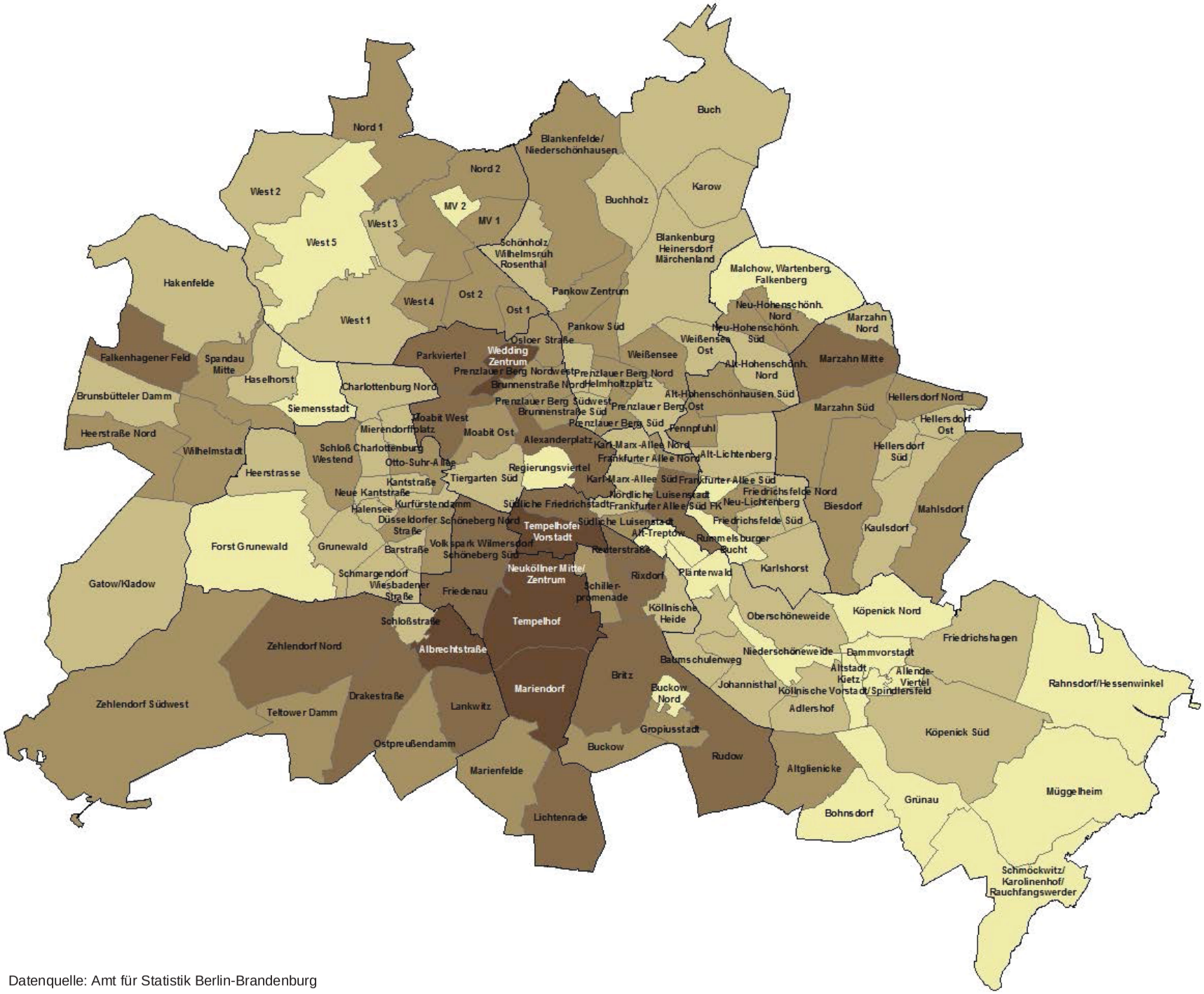

Datenquelle: Amt für Statistik Berlin-Brandenburg

Berlin

Der Polizeipräsident in Berlin

Einwohnerzahlen
(Bezirksregionen)

Stand: 30.06.2013

Einwohner je Bezirksregion

- bis 12 500 Einwohner
- über 12 500 bis 25 000 Einwohner
- über 25 000 bis 37 500 Einwohner
- über 37 500 bis 50 000 Einwohner
- über 50 000 Einwohner
- Bezirksgrenze

© **Der Polizeipräsident in Berlin**
Landeskriminalamt

Berlin - Straftaten -insgesamt- (Häufigkeitszahl)

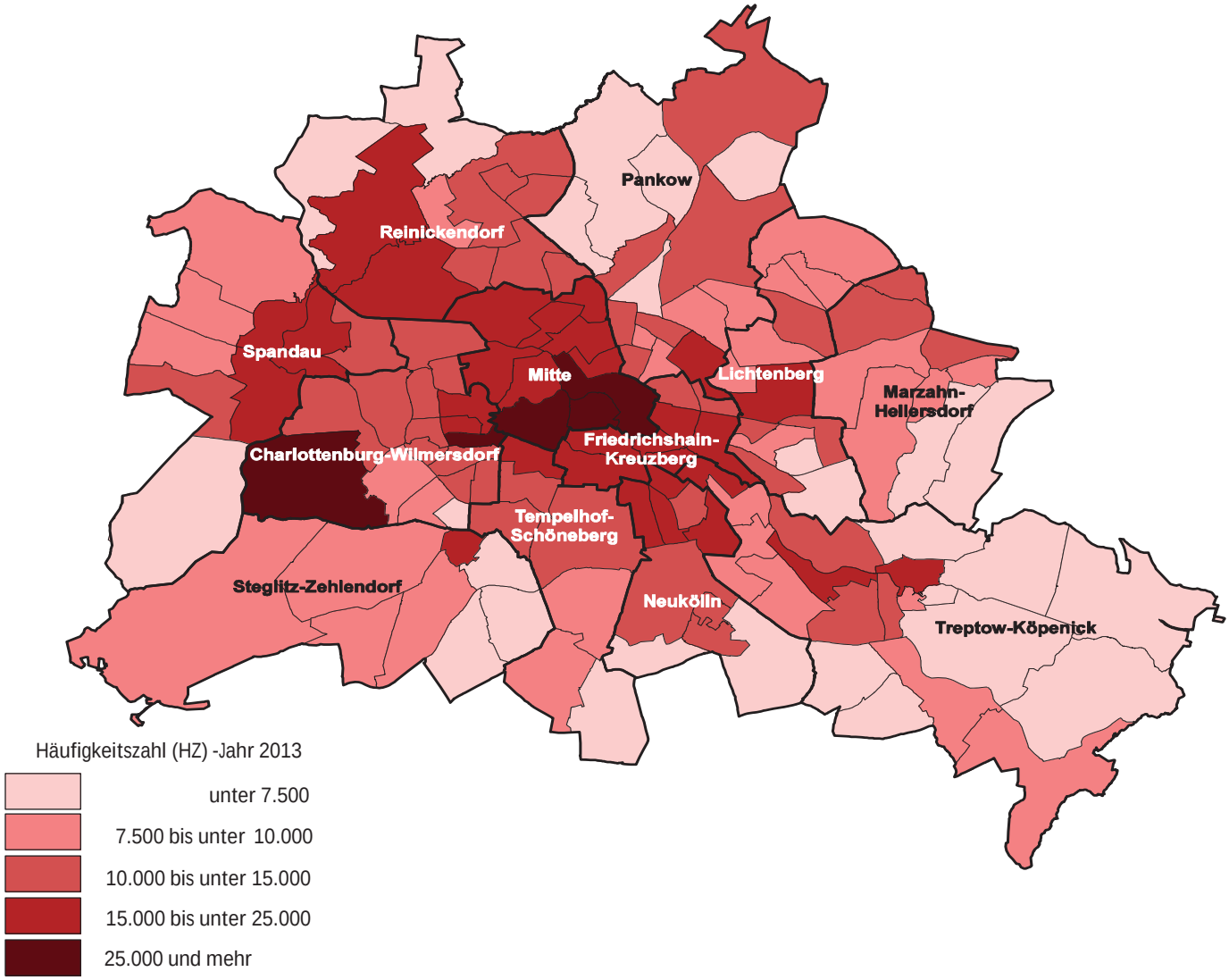

Straftaten -insgesamt- (PKS-Schlüssel ------)

Bezirk	Jahr 2012		Jahr 2013		Zu-/Abnahme			
	erfasste Fälle	HZ	erfasste Fälle	HZ	Fälle absolut	Fälle in %	HZ absolut	HZ in %
Mitte	85 561	25 498	86 935	25 303	1 374	1,6	- 195	- 0,8
Friedrichshain-Kreuzberg	50 187	18 806	52 647	19 413	2 460	4,9	607	3,2
Pankow	39 312	10 703	39 089	10 458	- 223	- 0,6	- 245	- 2,3
Charlottenburg-Wilmersdorf	50 719	16 012	51 527	16 061	808	1,6	49	0,3
Spandau	27 233	12 299	28 119	12 527	886	3,3	228	1,9
Steglitz-Zehlendorf	25 678	8 729	26 876	9 065	1 198	4,7	336	3,8
Tempelhof-Schöneberg	39 204	11 978	41 115	12 485	1 911	4,9	507	4,2
Neukölln	44 793	14 191	44 822	13 989	29	0,1	- 202	- 1,4
Treptow-Köpenick	22 779	9 402	23 394	9 561	615	2,7	159	1,7
Marzahn-Hellersdorf	24 915	9 954	24 943	9 859	28	0,1	- 95	- 1,0
Lichtenberg	27 470	10 628	26 202	9 983	- 1 268	- 4,6	- 645	- 6,1
Reinickendorf	30 518	12 408	29 817	11 963	- 701	- 2,3	- 445	- 3,6
Berlin, nicht zuzuordnen	26 928		27 679					
Berlin -Gesamt-	**495 297**	**14 390**	**503 165**	**14 419**	**7 868**	**1,6**	**29**	**0,2**

Bezirk Berlin Mitte

Straftaten -insgesamt (Häufigkeitszahl)

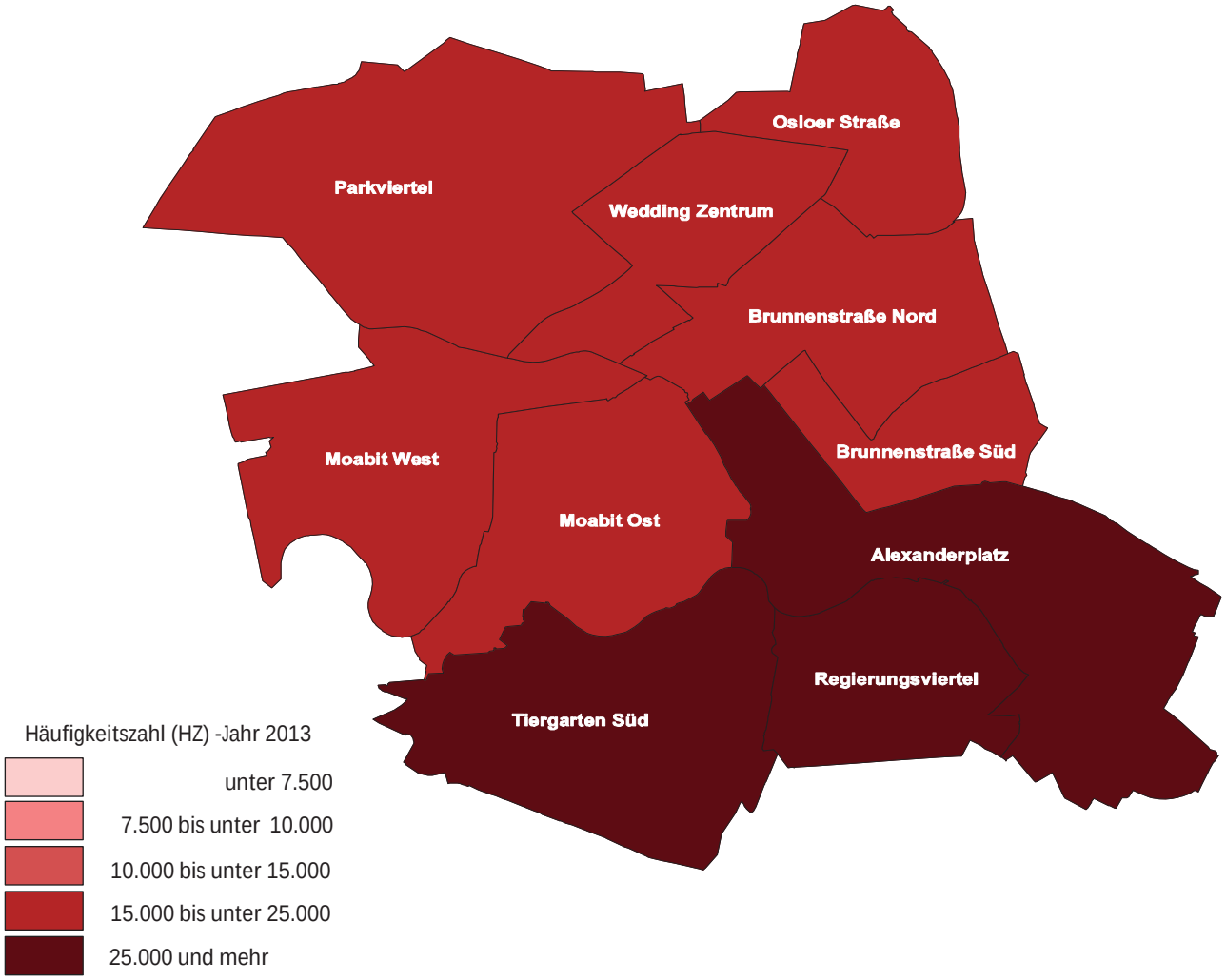

Straftaten -insgesamt- (PKS-Schlüssel ------)

Bezirksregion	Jahr 2012		Jahr 2013		Zu-/Abnahme			
	erfasste Fälle	HZ	erfasste Fälle	HZ	Fälle		HZ	
					absolut	in %	absolut	in %
Tiergarten Süd.....	5 096	40 444	5 494	42 229	398	7,8	1 785	4,4
Regierungsviertel.....	6 625	72 270	6 987	75 145	362	5,5	2 875	4,0
Alexanderplatz.....	19 211	40 707	19 097	39 673	- 114	- 0,6	- 1 034	- 2,5
Brunnenstraße Süd.....	4 015	15 704	4 368	16 446	353	8,8	742	4,7
Moabit West.....	7 343	17 530	6 620	15 479	- 723	- 9,8	- 2 051	- 11,7
Moabit Ost.....	6 128	17 594	7 021	19 882	893	14,6	2 288	13,0
Osloer Straße.....	7 889	22 509	7 870	21 743	- 19	- 0,2	- 766	- 3,4
Brunnenstraße Nord.....	6 336	17 954	6 818	19 027	482	7,6	1 073	6,0
Parkviertel.....	6 870	16 576	6 832	16 131	- 38	- 0,6	- 445	- 2,7
Wedding Zentrum.....	9 527	18 134	9 348	17 275	- 179	- 1,9	- 859	- 4,7
nicht zuzuordnen.....	6 521	-	6 480	-				

Bezirk Berlin Friedrichshain-Kreuzberg

Straftaten -insgesamt (Häufigkeitszahl)

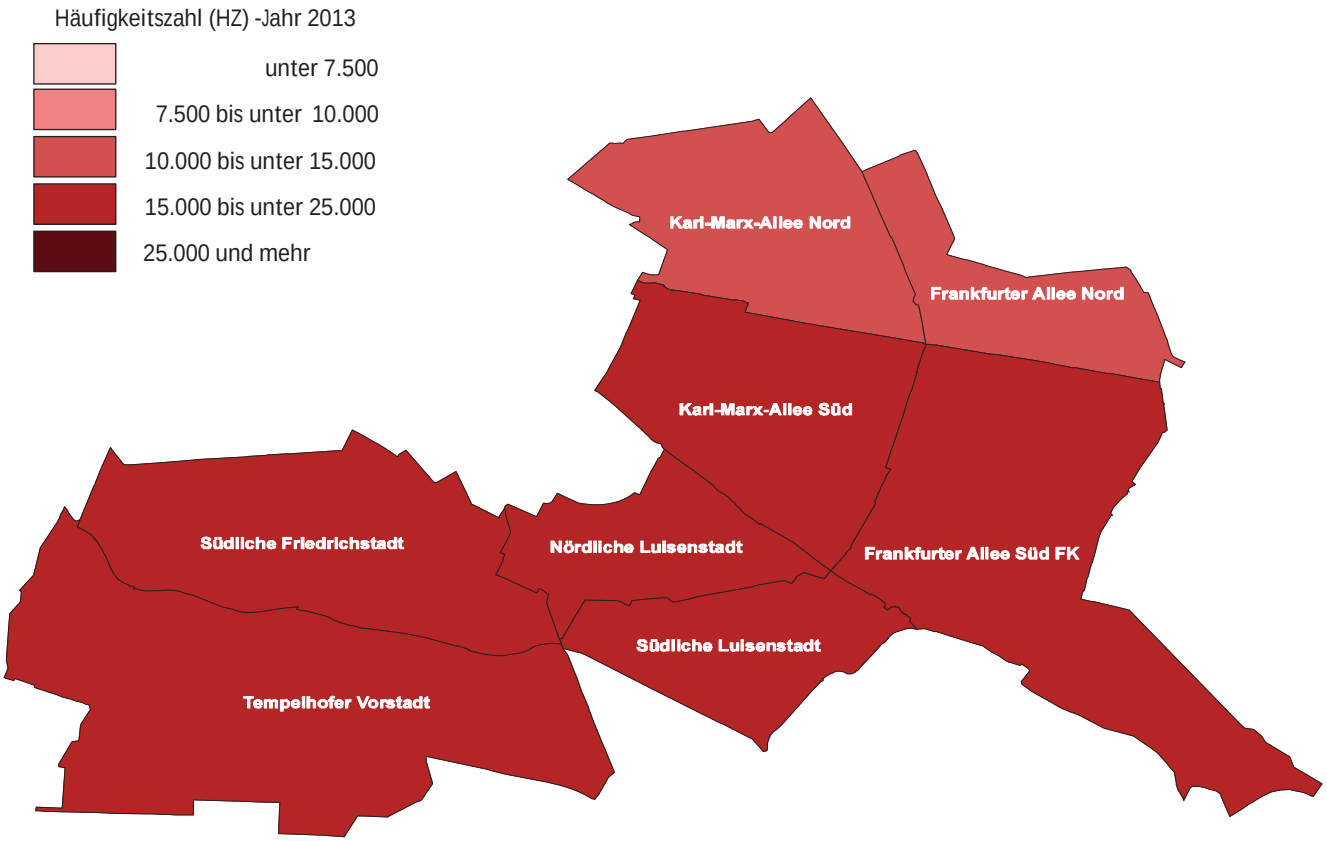

Straftaten -insgesamt- (PKS-Schlüssel ------)

Bezirksregion	Jahr 2012		Jahr 2013		Zu-/Abnahme			
	erfasste Fälle	HZ	erfasste Fälle	HZ	Fälle		HZ	
					absolut	in %	absolut	in %
Südliche Friedrichstadt.....	7 779	19 970	7 957	20 140	178	2,3	170	0,9
Tempelhofer Vorstadt.....	10 688	17 545	10 478	16 913	- 210	- 2,0	- 632	- 3,6
Nördliche Luisenstadt.....	4 951	22 164	5 543	24 585	592	12,0	2 421	10,9
Südliche Luisenstadt.....	4 379	16 778	5 815	21 996	1 436	32,8	5 218	31,1
Karl-Marx-Allee Nord.....	2 693	12 098	2 453	10 912	- 240	- 8,9	- 1 186	- 9,8
Karl-Marx-Allee Süd.....	5 569	24 275	5 551	23 710	- 18	- 0,3	- 565	- 2,3
Frankfurter Allee Nord.....	3 580	13 180	3 817	13 830	237	6,6	650	4,9
Frankfurter Allee Süd FK.....	8 080	17 490	8 693	18 394	613	7,6	904	5,2
nicht zuzuordnen.....	2 468		2 340					

Bezirk Berlin Pankow

Straftaten -insgesamt (Häufigkeitszahl)

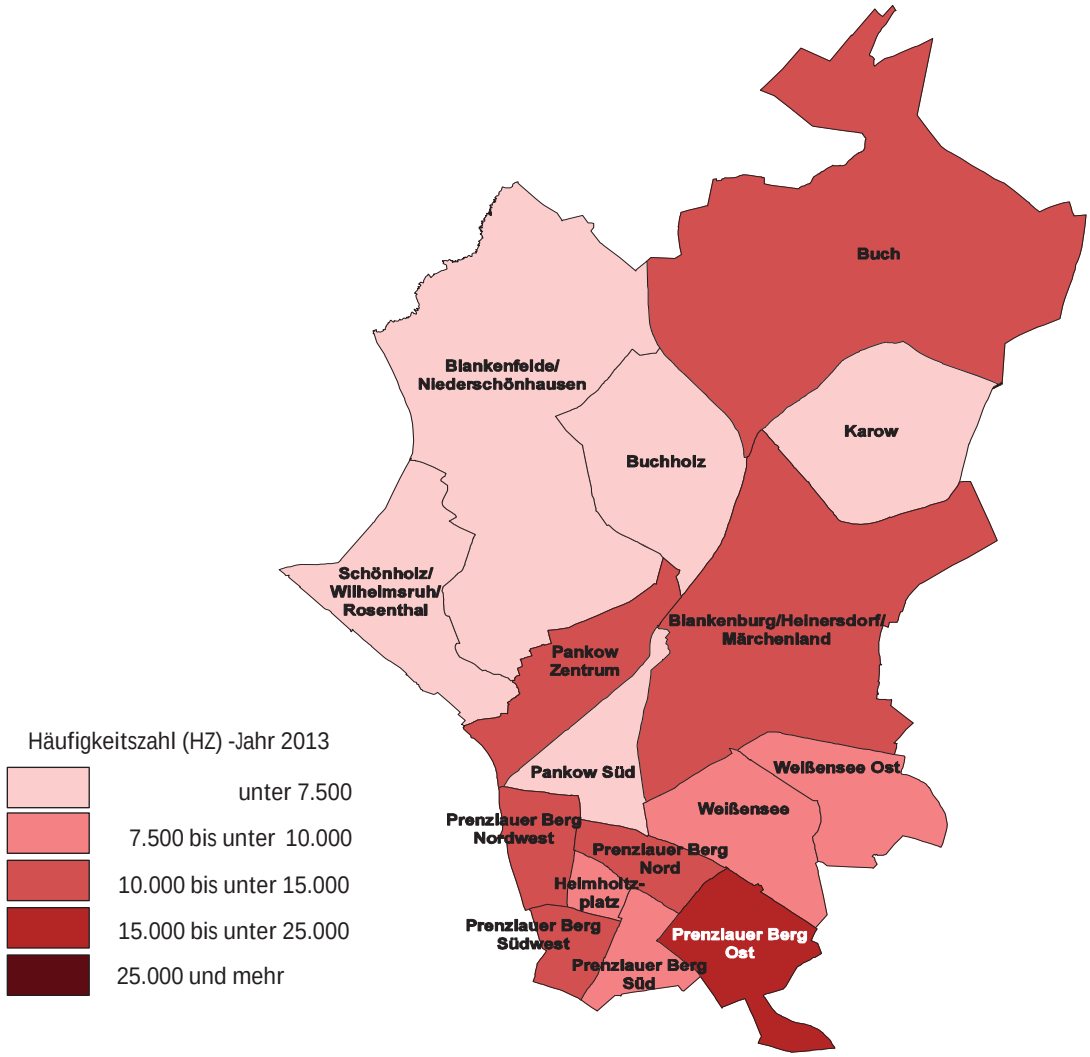

Straftaten -insgesamt- (PKS-Schlüssel ------)

Bezirksregion	Jahr 2012		Jahr 2013		Zu-/Abnahme			
	erfasste Fälle	HZ	erfasste Fälle	HZ	Fälle absolut	Fälle in %	HZ absolut	HZ in %
Buch	1 791	13 737	1 586	11 707	- 205	- 11,4	- 2 030	- 14,8
Blankenfelde/Niederschönhausen	1 708	6 746	1 795	6 906	87	5,1	160	2,4
Buchholz	1 013	6 036	1 012	5 956	- 1	- 0,1	- 80	- 1,3
Karow	868	4 643	910	4 886	42	4,8	243	5,2
Blankenburg/Heinersdorf	1 597	11 305	1 490	10 537	- 107	- 6,7	- 768	- 6,8
Pankow Süd	2 471	7 762	2 386	7 349	- 85	- 3,4	- 413	- 5,3
Schönholz/Wilhelmsruh/Rosenthal	1 209	7 058	1 043	6 078	- 166	- 13,7	- 980	- 13,9
Pankow Zentrum	3 617	11 147	3 711	11 135	94	2,6	- 12	- 0,1
Weißensee	3 317	10 068	3 284	9 770	- 33	- 1,0	- 298	- 3,0
Weißensee Ost	1 376	9 171	1 420	9 383	44	3,2	212	2,3
Prenzlauer Berg Nordwest	3 396	14 377	3 146	12 972	- 250	- 7,4	- 1 405	- 9,8
Prenzlauer Berg Nord	3 239	12 549	3 208	12 297	- 31	- 1,0	- 252	- 2,0
Helmholtzplatz	2 395	11 295	2 128	9 822	- 267	- 11,1	- 1 473	- 13,0
Prenzlauer Berg Ost	3 743	15 408	3 974	16 020	231	6,2	612	4,0
Prenzlauer Berg Südwest	3 678	15 175	3 717	14 983	39	1,1	- 192	- 1,3
Prenzlauer Berg Süd	2 762	8 965	3 012	9 672	250	9,1	707	7,9
nicht zuzuordnen	1 132		1 267					

Bezirk Berlin Charlottenburg-Wilmersdorf

Straftaten -insgesamt (Häufigkeitszahl)

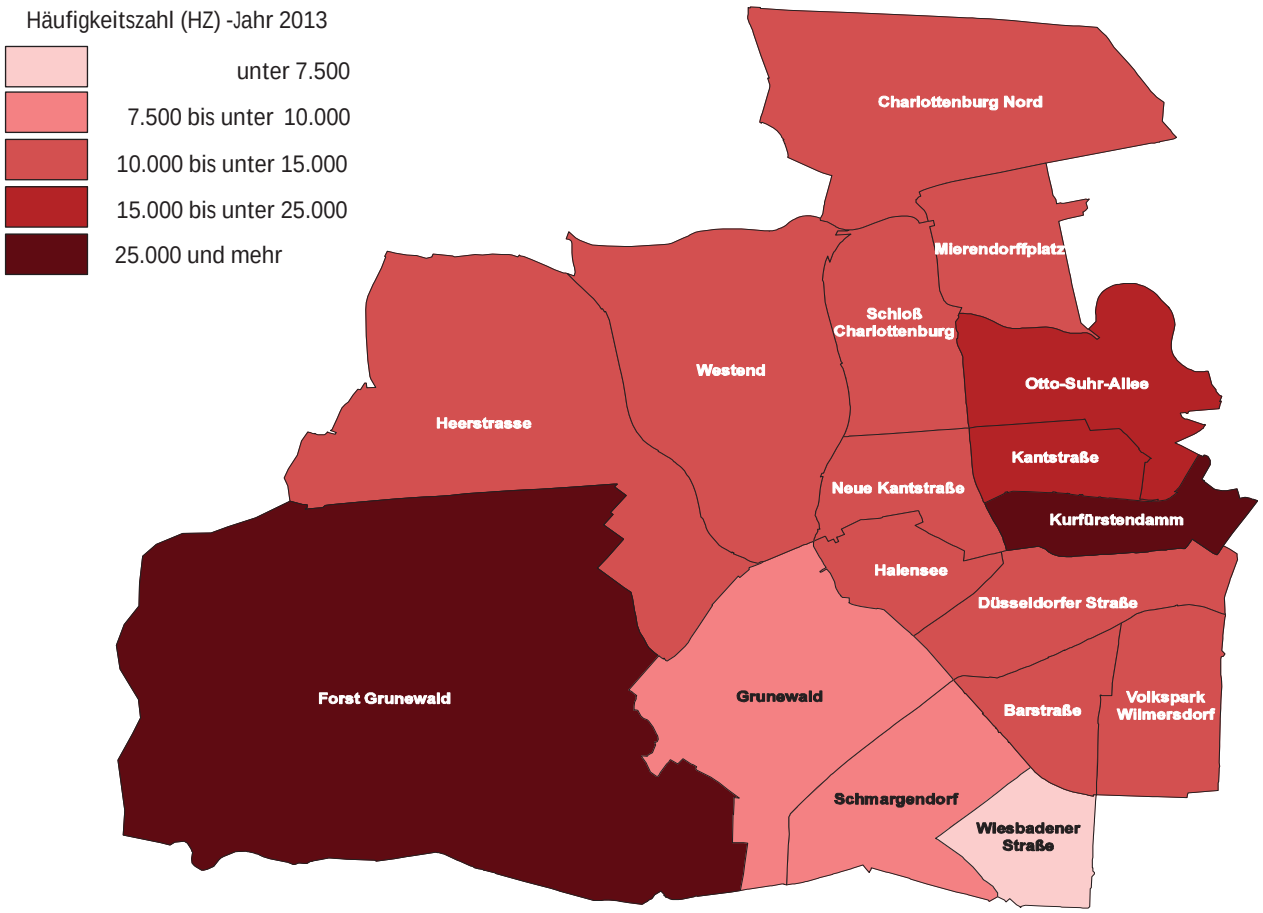

Straftaten -insgesamt- (PKS-Schlüssel ------)

Bezirksregion	Jahr 2012		Jahr 2013		Zu-/Abnahme			
	erfasste Fälle	HZ	erfasste Fälle	HZ	Fälle absolut	Fälle in %	HZ absolut	HZ in %
Charlottenburg Nord.....	2 605	14 402	2 730	14 784	125	4,8	382	2,7
Heerstraße.....	1 446	11 569	1 425	11 298	- 21	- 1,5	- 271	- 2,3
Westend.....	3 829	14 625	3 977	14 928	148	3,9	303	2,1
Schloß Charlottenburg.....	2 435	10 519	2 435	10 393		-	- 126	- 1,2
Mierendorffplatz.....	1 990	13 986	1 874	12 850	- 116	- 5,8	- 1 136	- 8,1
Otto-Suhr-Allee.....	4 836	18 982	5 000	19 392	164	3,4	410	2,2
Neue Kantstraße.....	2 602	11 347	2 985	12 878	383	14,7	1 531	13,5
Kantstraße.....	5 109	24 965	5 035	24 299	- 74	- 1,4	- 666	- 2,7
Kurfürstendamm.....	8 653	59 422	8 737	59 896	84	1,0	474	0,8
Halensee.....	1 965	13 842	2 114	14 656	149	7,6	814	5,9
Grunewald.....	1 576	8 804	1 667	9 149	91	5,8	345	3,9
Schmargendorf.....	1 324	9 585	1 244	8 945	- 80	- 6,0	- 640	- 6,7
Wiesbadener Straße.....	1 160	6 435	1 175	6 503	15	1,3	68	1,1
Düsseldorfer Straße.....	3 831	13 064	3 855	12 958	24	0,6	- 106	- 0,8
Barstraße.....	1 643	12 178	1 726	12 719	83	5,1	541	4,4
Volkspark Wilmersdorf.....	3 519	10 876	3 353	10 223	- 166	- 4,7	- 653	- 6,0
Forst Grunewald.....	138		147		9	6,5		
nicht zuzuordnen.....	2 058		2 048					

Bezirk Berlin Spandau

Straftaten -insgesamt (Häufigkeitszahl)

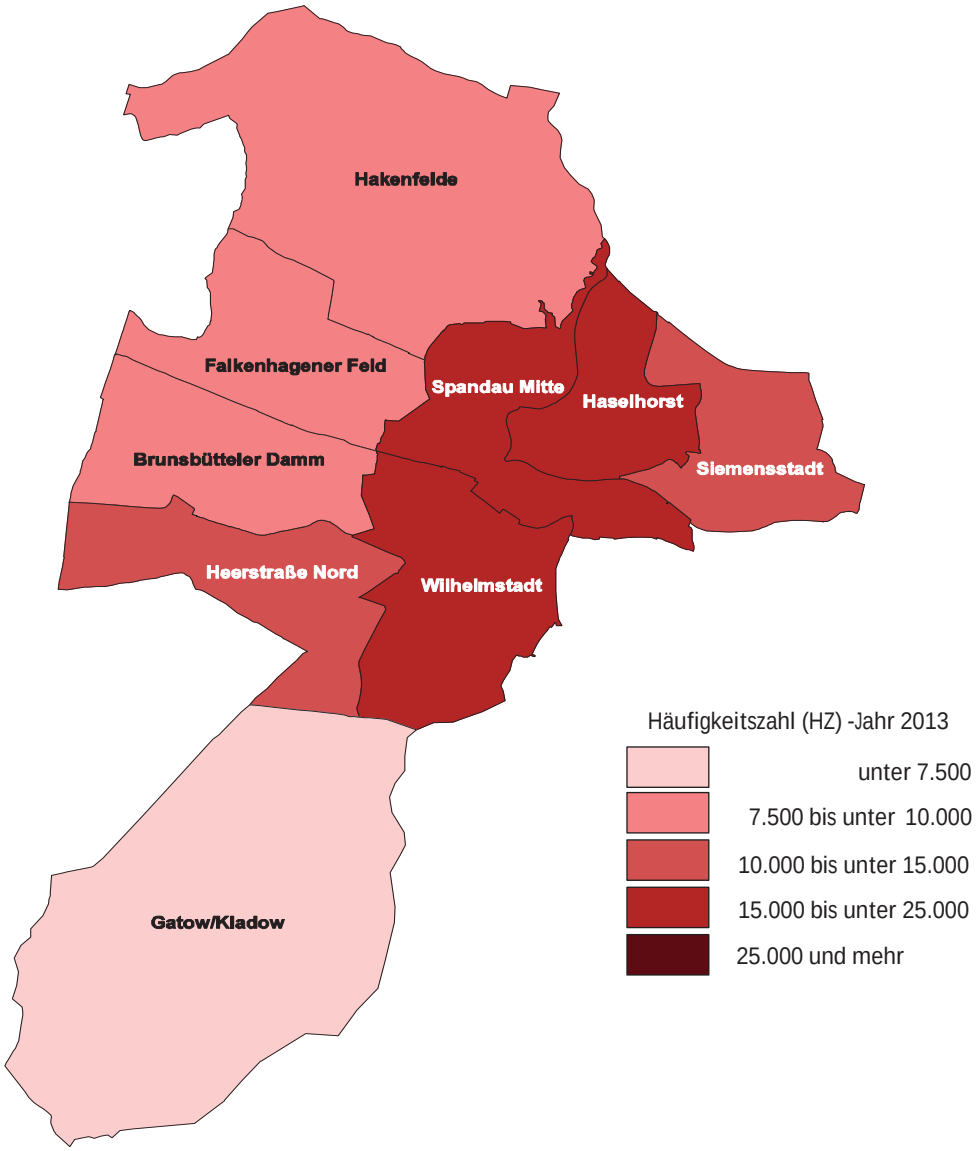

Straftaten -insgesamt- (PKS-Schlüssel ------)

Bezirksregion	Jahr 2012		Jahr 2013		Zu-/Abnahme			
	erfasste Fälle	HZ	erfasste Fälle	HZ	Fälle		HZ	
					absolut	in %	absolut	in %
Hakenfelde.....	1 996	8 807	2 034	8 957	38	1,9	150	1,7
Falkenhagener Feld.....	3 247	8 323	3 041	7 754	- 206	- 6,3	- 569	- 6,8
Spandau Mitte.....	6 065	18 457	6 492	19 260	427	7,0	803	4,4
Brunsbütteler Damm.....	1 716	7 413	1 829	7 912	113	6,6	499	6,7
Heerstraße Nord.....	3 058	11 459	3 002	11 210	- 56	- 1,8	- 249	- 2,2
Wilhelmstadt.....	5 122	15 114	5 832	16 972	710	13,9	1 858	12,3
Haselhorst.....	2 340	16 997	2 169	15 028	- 171	- 7,3	- 1 969	- 11,6
Siemensstadt.....	1 654	14 229	1 655	13 803	1	0,1	- 426	- 3,0
Gatow/Kladow.....	910	5 122	1 005	5 538	95	10,4	416	8,1
nicht zuzuordnen.....	1 125		1 060					

Bezirk Berlin Steglitz-Zehlendorf

Straftaten -insgesamt (Häufigkeitszahl)

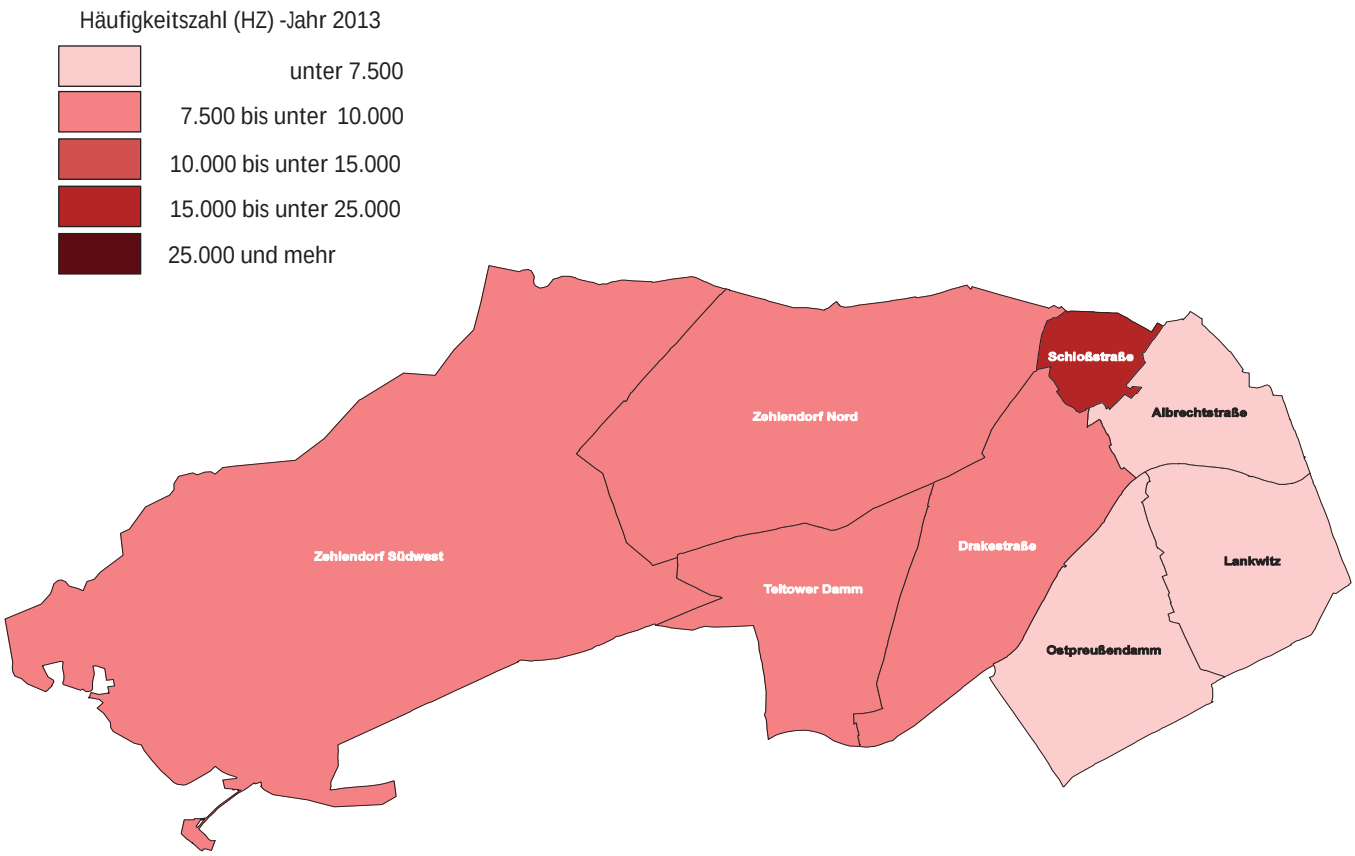

Straftaten -insgesamt- (PKS-Schlüssel ------)

Bezirksregion	Jahr 2012		Jahr 2013		Zu-/Abnahme			
	erfasste Fälle	HZ	erfasste Fälle	HZ	Fälle absolut	Fälle in %	HZ absolut	HZ in %
Schloßstraße.....	4 250	19 860	4 723	21 852	473	11,1	1 992	10,0
Albrechtstraße.....	3 506	6 829	3 292	6 359	- 214	- 6,1	- 470	- 6,9
Lankwitz.....	2 864	6 926	3 117	7 461	253	8,8	535	7,7
Ostpreußendamm.....	2 440	7 040	2 571	7 351	131	5,4	311	4,4
Teltower Damm.....	2 438	7 459	2 562	7 817	124	5,1	358	4,8
Drakestraße.....	3 317	7 258	3 494	7 512	177	5,3	254	3,5
Zehlendorf Südwest.....	2 222	8 710	2 367	9 265	145	6,5	555	6,4
Zehlendorf Nord.....	3 815	9 187	3 931	9 470	116	3,0	283	3,1
nicht zuzuordnen.....	826		819					

Bezirk Berlin Tempelhof-Schöneberg

Straftaten -insgesamt (Häufigkeitszahl)

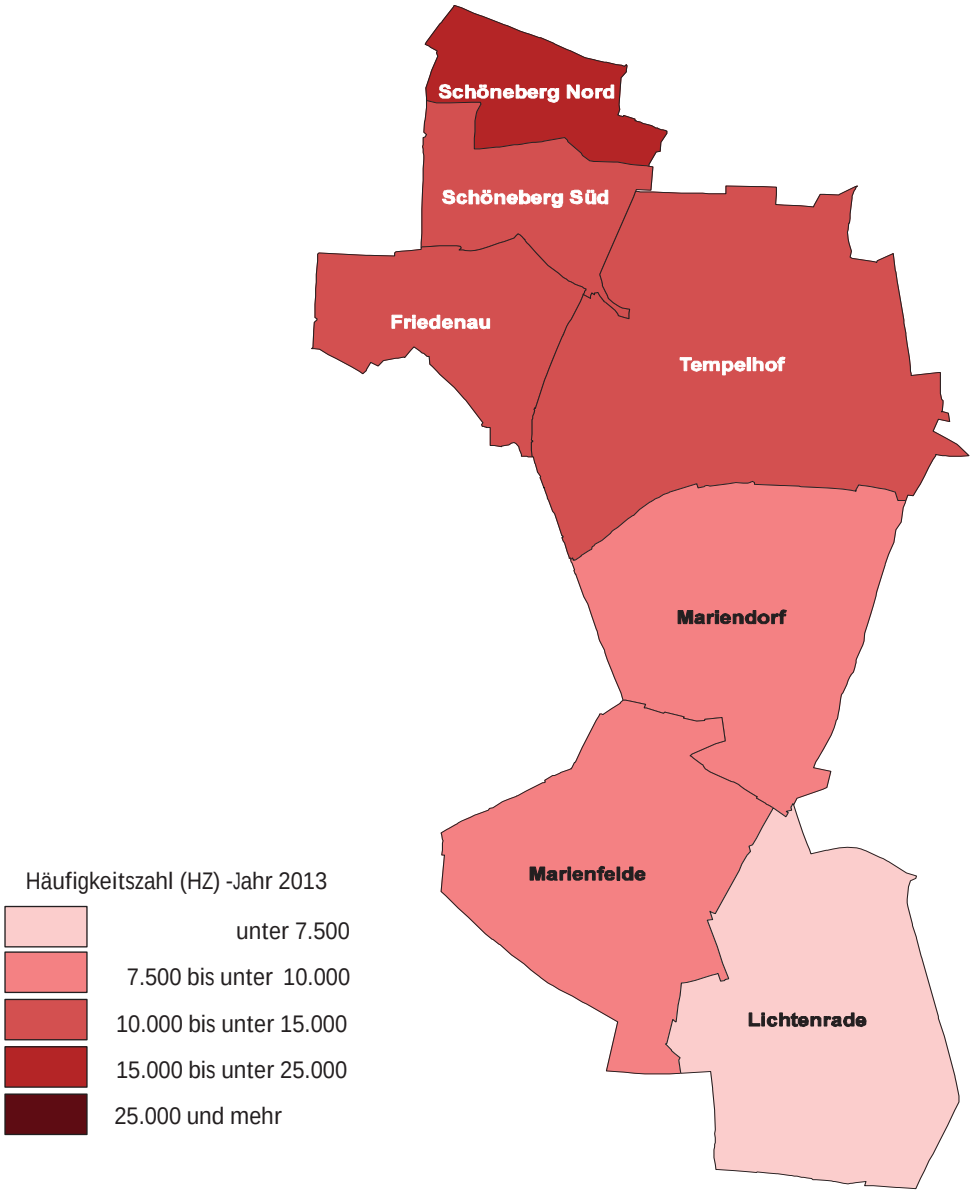

Straftaten -insgesamt- (PKS-Schlüssel ------)

Bezirksregion	Jahr 2012		Jahr 2013		Zu-/Abnahme			
	erfasste Fälle	HZ	erfasste Fälle	HZ	Fälle		HZ	
					absolut	in %	absolut	in %
Schöneberg Nord.....	8 546	18 142	9 376	19 973	830	9,7	1 831	10,1
Schöneberg Süd.....	6 165	12 972	6 281	13 172	116	1,9	200	1,5
Friedenau.....	4 212	9 572	5 092	11 469	880	20,9	1 897	19,8
Tempelhof.....	8 669	14 706	8 717	14 519	48	0,6	- 187	- 1,3
Mariendorf.....	4 223	8 476	4 437	8 873	214	5,1	397	4,7
Marienfelde.....	2 723	8 948	2 707	8 862	- 16	- 0,6	- 86	- 1,0
Lichtenrade.....	3 106	6 281	3 034	6 104	- 72	- 2,3	- 177	- 2,8
nicht zuzuordnen.....	1 560		1 471					

Bezirk Berlin Neukölln

Straftaten -insgesamt (Häufigkeitszahl)

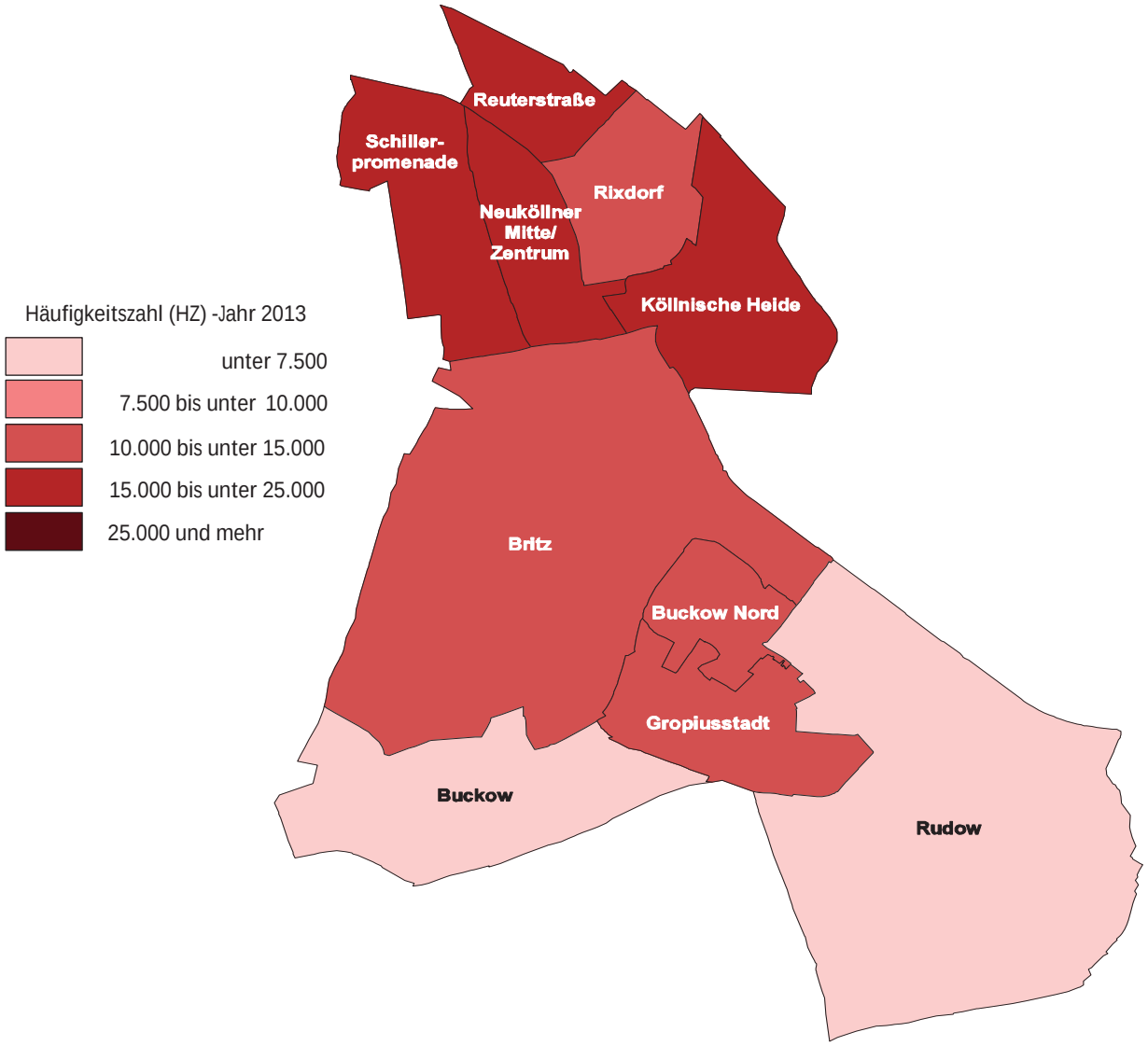

Straftaten -insgesamt- (PKS-Schlüssel ------)

Bezirksregion	Jahr 2012		Jahr 2013		Zu-/Abnahme			
	erfasste Fälle	HZ	erfasste Fälle	HZ	Fälle absolut	Fälle in %	HZ absolut	HZ in %
Schillerpromenade	6 427	20 781	6 035	19 118	- 392	- 6,1	- 1 663	- 8,0
Neuköllner Mitte/Zentrum	9 477	25 686	9 258	24 534	- 219	- 2,3	- 1 152	- 4,5
Reuterstraße	5 787	14 902	6 176	15 536	389	6,7	634	4,3
Rixdorf	5 052	12 998	5 243	13 264	191	3,8	266	2,0
Köllnische Heide	2 694	18 278	3 045	20 247	351	13,0	1 969	10,8
Britz	4 834	11 934	4 921	11 975	87	1,8	41	0,3
Buckow	1 856	6 722	1 642	5 896	- 214	- 11,5	- 826	- 12,3
Gropiusstadt	4 105	11 385	3 961	10 894	- 144	- 3,5	- 491	- 4,3
Buckow Nord	907	9 757	989	10 557	82	9,0	800	8,2
Rudow	2 907	6 934	2 783	6 608	- 124	- 4,3	- 326	- 4,7
nicht zuzuordnen	747		769					

Bezirk Berlin Treptow-Köpenick

Straftaten -insgesamt (Häufigkeitszahl)

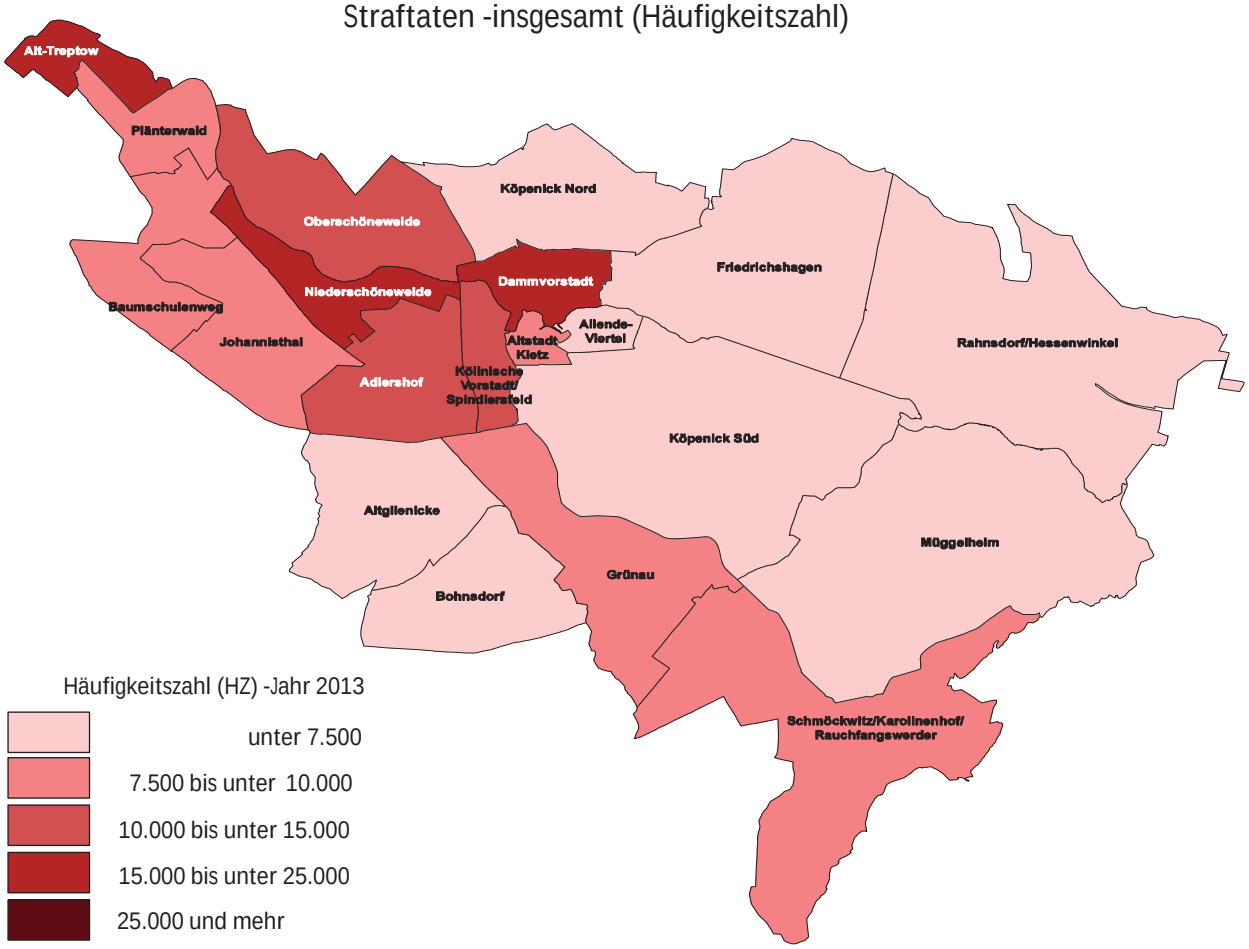

Straftaten -insgesamt- (PKS-Schlüssel ------)

Bezirksregion	Jahr 2012		Jahr 2013		Zu-/Abnahme			
	erfasste Fälle	HZ	erfasste Fälle	HZ	Fälle absolut	Fälle in %	HZ absolut	HZ in %
Alt-Treptow	1 906	17 445	2 006	18 077	100	5,2	632	3,6
Plänterwald	983	9 115	1 073	9 904	90	9,2	789	8,7
Baumschulenweg	1 464	8 495	1 457	8 360	- 7	- 0,5	- 135	- 1,6
Johannisthal	1 248	6 813	1 385	7 514	137	11,0	701	10,3
Oberschöneweide	2 286	11 929	2 620	13 288	334	14,6	1 359	11,4
Niederschöneweide	1 990	19 045	1 966	18 493	- 24	- 1,2	- 552	- 2,9
Adlershof	2 083	13 538	1 903	12 196	- 180	- 8,6	- 1 342	- 9,9
Kölln. Vorstadt/Spindlersf.	1 013	10 292	1 016	10 153	3	0,3	- 139	- 1,4
Altglienicke	1 321	5 171	1 389	5 369	68	5,1	198	3,8
Bohnsdorf	671	5 636	763	6 326	92	13,7	690	12,2
Grünau	495	9 170	476	8 495	- 19	- 3,8	- 675	- 7,4
Schmöckwitz/Karolinenhof	509	12 531	333	8 265	- 176	- 34,6	- 4 266	- 34,0
Köpenick Süd	827	5 295	794	5 106	- 33	- 4,0	- 189	- 3,6
Allende-Viertel	424	6 944	375	6 126	- 49	- 11,6	- 818	- 11,8
Altstadt Kietz	636	9 259	601	8 659	- 35	- 5,5	- 600	- 6,5
Müggelheim	253	3 889	239	3 654	- 14	- 5,5	- 235	- 6,0
Friedrichshagen	959	5 487	997	5 708	38	4,0	221	4,0
Rahnsdorf/Hessenwinkel	483	5 388	587	6 552	104	21,5	1 164	21,6
Dammvorstadt	1 418	15 047	1 766	18 545	348	24,5	3 498	23,2
Köpenick Nord	574	4 670	585	4 768	11	1,9	98	2,1
nicht zuzuordnen	1 236		1 063					

Bezirk Berlin Marzahn-Hellersdorf

Straftaten -insgesamt (Häufigkeitszahl)

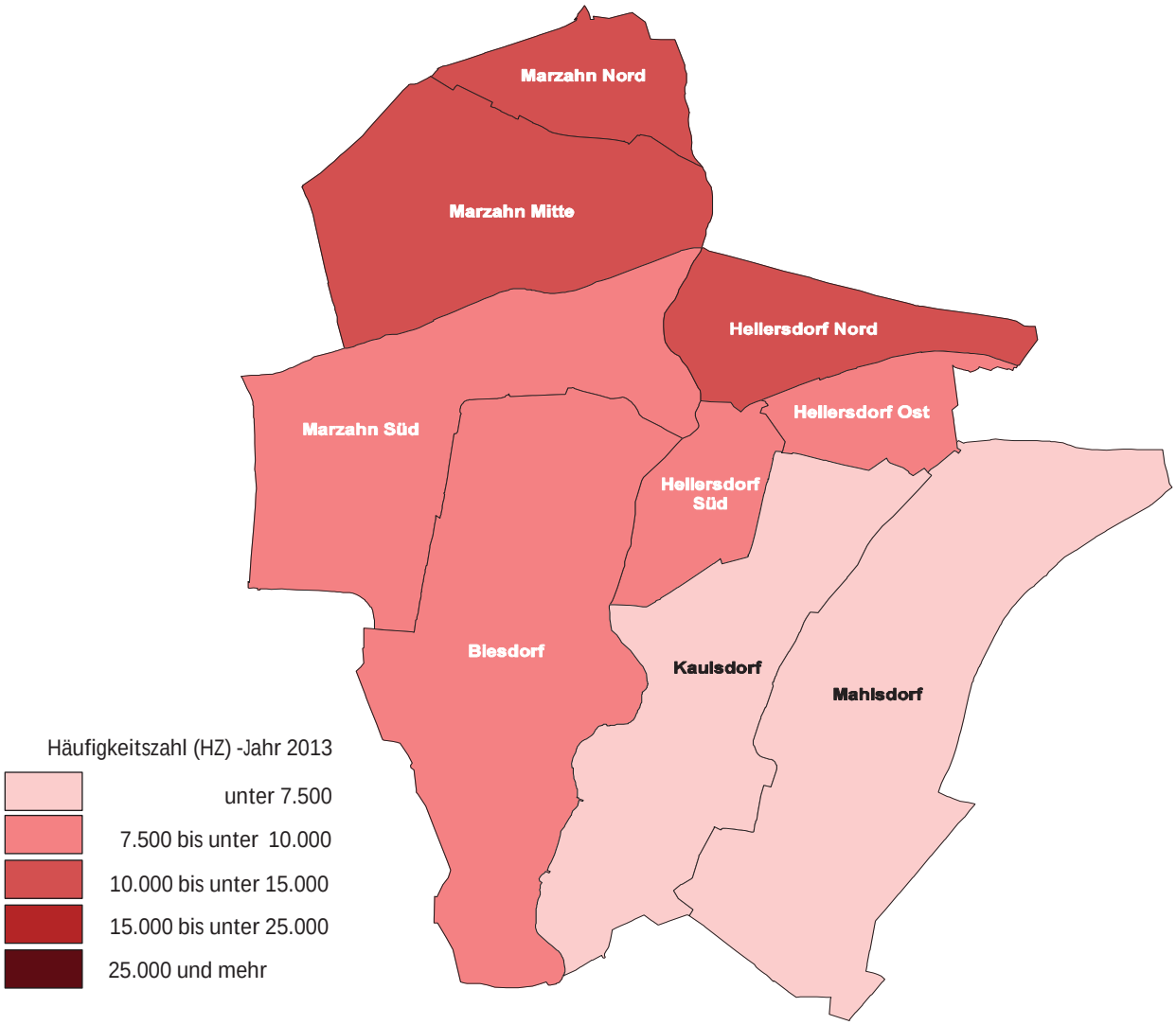

Straftaten -insgesamt- (PKS-Schlüssel ------)

Bezirksregion	Jahr 2012		Jahr 2013		Zu-/Abnahme			
	erfasste Fälle	HZ	erfasste Fälle	HZ	Fälle		HZ	
					absolut	in %	absolut	in %
Marzahn Nord	2 362	10 425	2 347	10 234	- 15	- 0,6	- 191	- 1,8
Marzahn Mitte	5 464	12 090	5 287	11 591	- 177	- 3,2	- 499	- 4,1
Marzahn Süd	3 475	9 623	3 601	9 842	126	3,6	219	2,3
Hellersdorf Nord	4 347	13 257	4 263	12 801	- 84	- 1,9	- 456	- 3,4
Hellersdorf Ost	1 840	9 974	1 641	8 693	- 199	- 10,8	- 1 281	- 12,8
Hellersdorf Süd	1 842	7 593	1 923	7 873	81	4,4	280	3,7
Biesdorf	2 108	8 382	2 317	9 083	209	9,9	701	8,4
Kaulsdorf	1 126	6 021	1 113	5 968	- 13	- 1,2	- 53	- 0,9
Mahlsdorf	1 474	5 462	1 493	5 508	19	1,3	46	0,8
nicht zuzuordnen	877		958					

Bezirk Berlin Lichtenberg

Straftaten -insgesamt (Häufigkeitszahl)

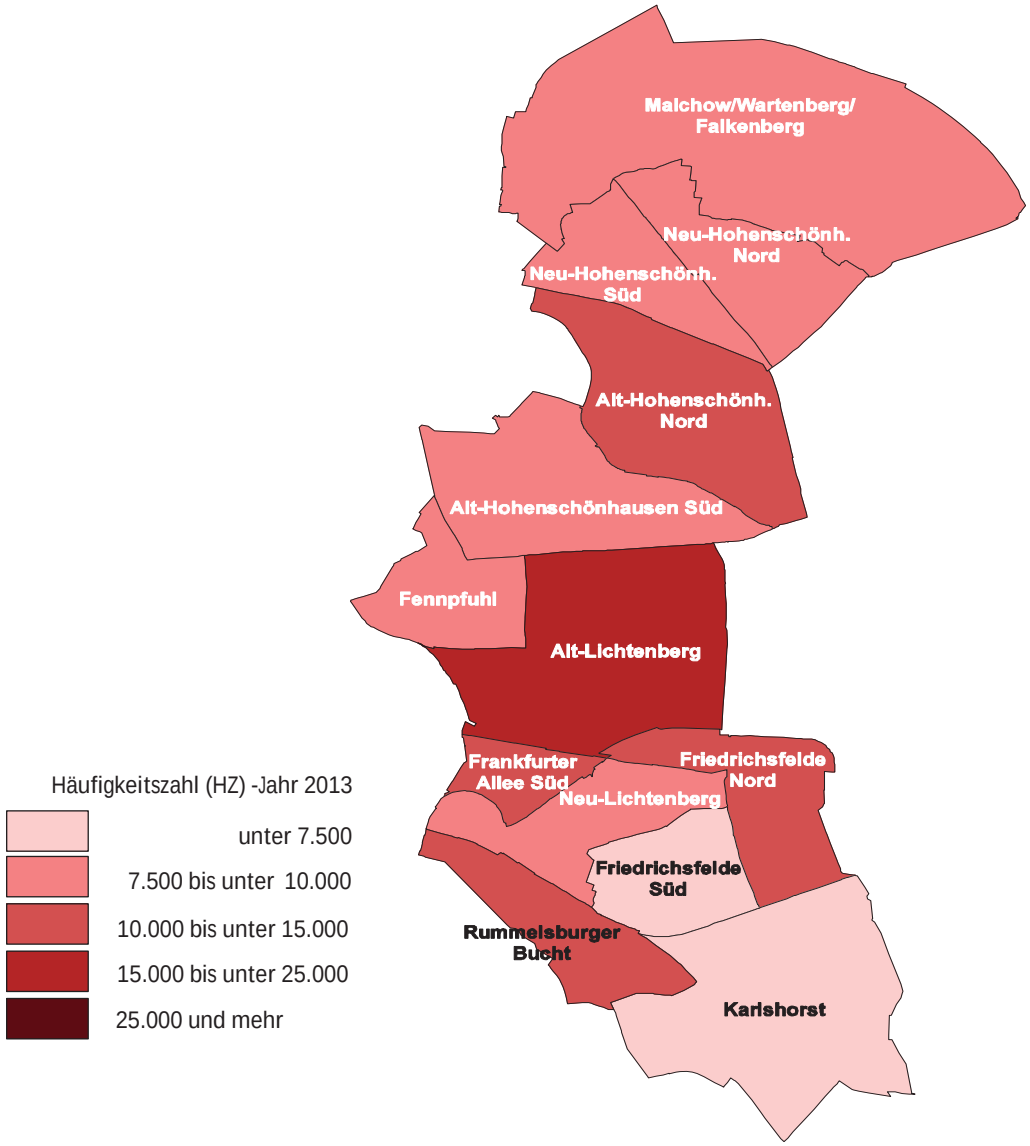

Straftaten -insgesamt- (PKS-Schlüssel ------)

Bezirksregion	Jahr 2012		Jahr 2013		Zu-/Abnahme			
	erfasste Fälle	HZ	erfasste Fälle	HZ	Fälle absolut	Fälle in %	HZ absolut	HZ in %
Malchow/Warten-/Falkenberg.....	365	8 707	407	9 581	42	11,5	874	10,0
Neu-Hohenschönhausen Nord.....	2 173	7 905	2 191	7 914	18	0,8	9	0,1
Neu-Hohenschönhausen Süd.....	2 414	9 329	2 346	9 075	- 68	- 2,8	- 254	- 2,7
Alt-Hohenschönhausen Nord.....	1 490	11 060	1 672	12 395	182	12,2	1 335	12,1
Alt-Hohenschönhausen Süd.....	2 552	8 686	2 630	8 927	78	3,1	241	2,8
Fennpfuhl.....	3 594	11 330	2 456	7 672	- 1 138	- 31,7	- 3 658	- 32,3
Alt-Lichtenberg.....	4 171	17 366	4 191	16 806	20	0,5	- 560	- 3,2
Frankfurter Allee Süd.....	1 180	12 214	1 284	12 811	104	8,8	597	4,9
Neu-Lichtenberg.....	2 955	10 063	2 872	9 559	- 83	- 2,8	- 504	- 5,0
Friedrichsfelde Nord.....	1 525	11 442	1 525	11 280		-	- 162	- 1,4
Friedrichsfelde Süd.....	1 756	7 283	1 631	6 637	- 125	- 7,1	- 646	- 8,9
Rummelsburger Bucht.....	407	12 473	368	11 101	- 39	- 9,6	- 1 372	- 11,0
Karlshorst.....	1 333	5 902	1 548	6 641	215	16,1	739	12,5
nicht zuzuordnen.....	1 555		1 081					

Bezirk Berlin Reinickendorf

Straftaten -insgesamt (Häufigkeitszahl)

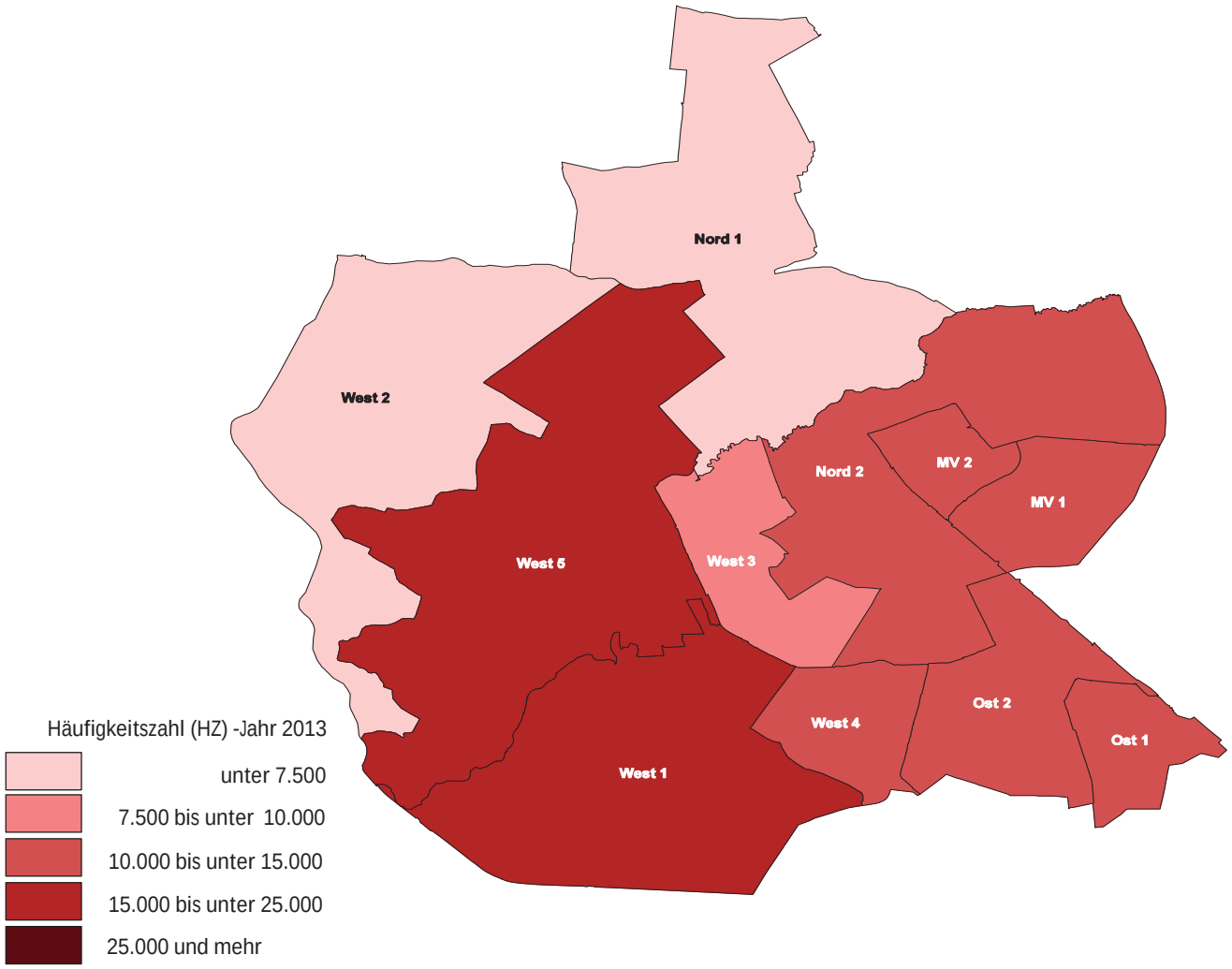

Straftaten -insgesamt- (PKS-Schlüssel ------)

Bezirksregion	Jahr 2012		Jahr 2013		Zu-/Abnahme			
	erfasste Fälle	HZ	erfasste Fälle	HZ	Fälle		HZ	
					absolut	in %	absolut	in %
Ost 1.....	3 097	12 072	2 957	11 380	- 140	- 4,5	- 692	- 5,7
Ost 2.....	3 550	13 918	3 410	13 188	- 140	- 3,9	- 730	- 5,2
West 1.....	3 473	23 873	3 070	21 219	- 403	- 11,6	- 2 654	- 11,1
West 4.....	3 429	13 720	3 463	13 623	34	1,0	- 97	- 0,7
West 5.....	2 231	21 838	1 980	19 236	- 251	- 11,3	- 2 602	- 11,9
West 2.....	1 405	5 961	1 308	5 501	- 97	- 6,9	- 460	- 7,7
Nord 1.....	2 028	6 204	2 051	6 249	23	1,1	45	0,7
Nord 2.....	3 196	10 949	3 330	11 187	134	4,2	238	2,2
MV 1.....	4 343	12 262	4 457	12 253	114	2,6	- 9	- 0,1
MV 2.....	951	11 606	1 092	12 844	141	14,8	1 238	10,7
West 3.....	1 387	8 683	1 337	8 362	- 50	- 3,6	- 321	- 3,7
nicht zuzuordnen.....	1 428		1 972					

Berlin - Kiezbezogene Straftaten (Häufigkeitszahl)

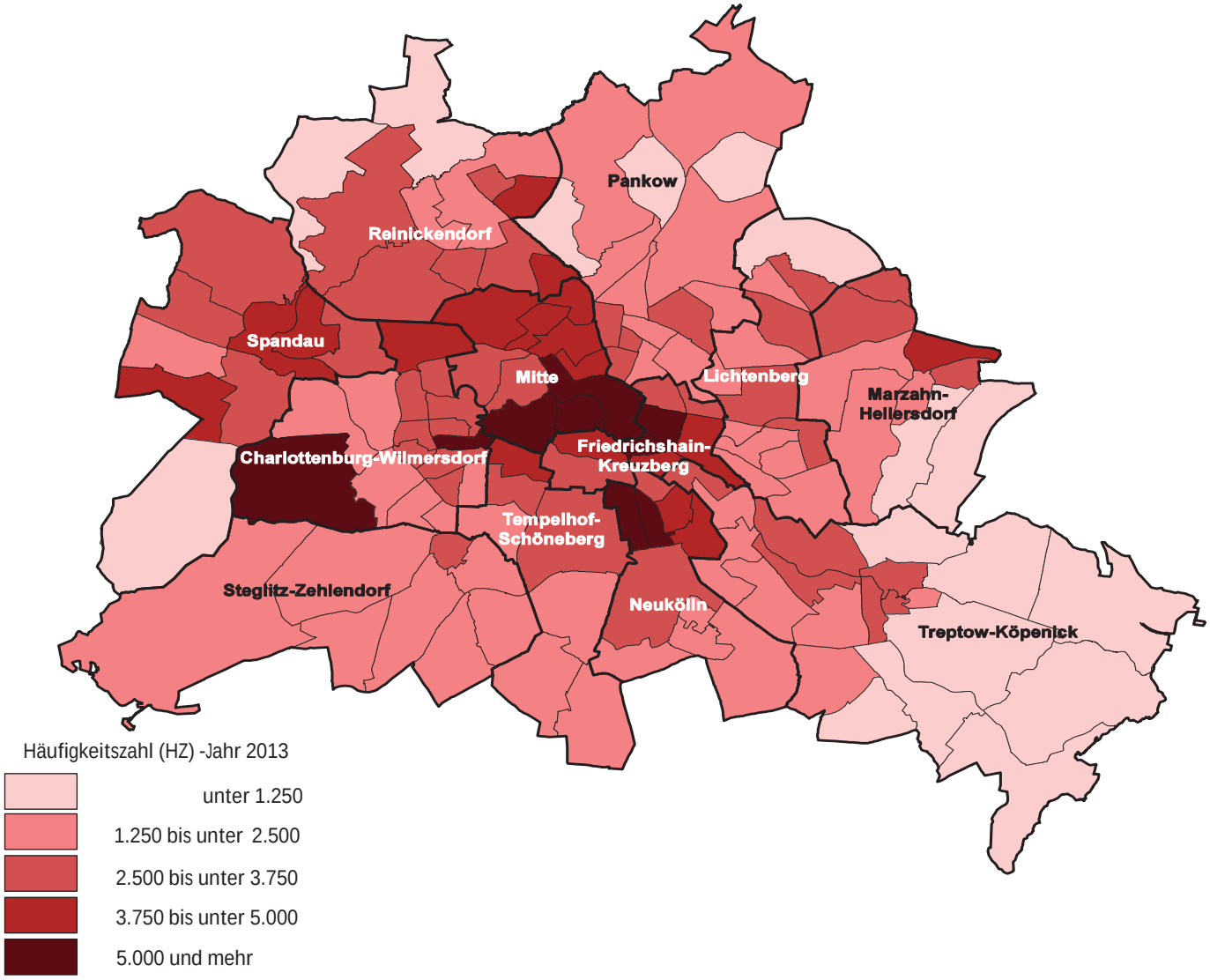

Kiezbezogene Straftaten (Deliktauswahl siehe 'Technische Hinweise')

Bezirk	Jahr 2012		Jahr 2013		Zu-/Abnahme			
	erfasste Fälle	HZ	erfasste Fälle	HZ	Fälle absolut	Fälle in %	HZ absolut	HZ in %
Mitte	16 545	4 930	16 308	4 746	- 237	- 1,4	- 184	- 3,7
Friedrichshain-Kreuzberg	11 001	4 122	11 289	4 163	288	2,6	41	1,0
Pankow	8 441	2 298	8 374	2 241	- 67	- 0,8	- 57	- 2,5
Charlottenburg-Wilmersdorf	9 997	3 156	10 074	3 140	77	0,8	- 16	- 0,5
Spandau	7 225	3 263	7 364	3 281	139	1,9	18	0,6
Steglitz-Zehlendorf	4 818	1 638	5 014	1 691	196	4,1	53	3,2
Tempelhof-Schöneberg	8 263	2 525	8 412	2 554	149	1,8	29	1,1
Neukölln	11 342	3 593	10 509	3 280	- 833	- 7,3	- 313	- 8,7
Treptow-Köpenick	4 571	1 887	4 660	1 904	89	1,9	17	0,9
Marzahn-Hellersdorf	6 202	2 478	6 230	2 462	28	0,5	- 16	- 0,6
Lichtenberg	6 252	2 419	6 102	2 325	- 150	- 2,4	- 94	- 3,9
Reinickendorf	6 815	2 771	6 780	2 720	- 35	- 0,5	- 51	- 1,8
Berlin, nicht zuzuordnen	1 106		1 157					
Berlin -Gesamt-	**102 578**	**3 043**	**102 273**	**3 004**	**- 305**	**-0,3**	**- 39**	**-1,3**

Bezirk Berlin Mitte

Kiezbezogene Straftaten (Häufigkeitszahl)

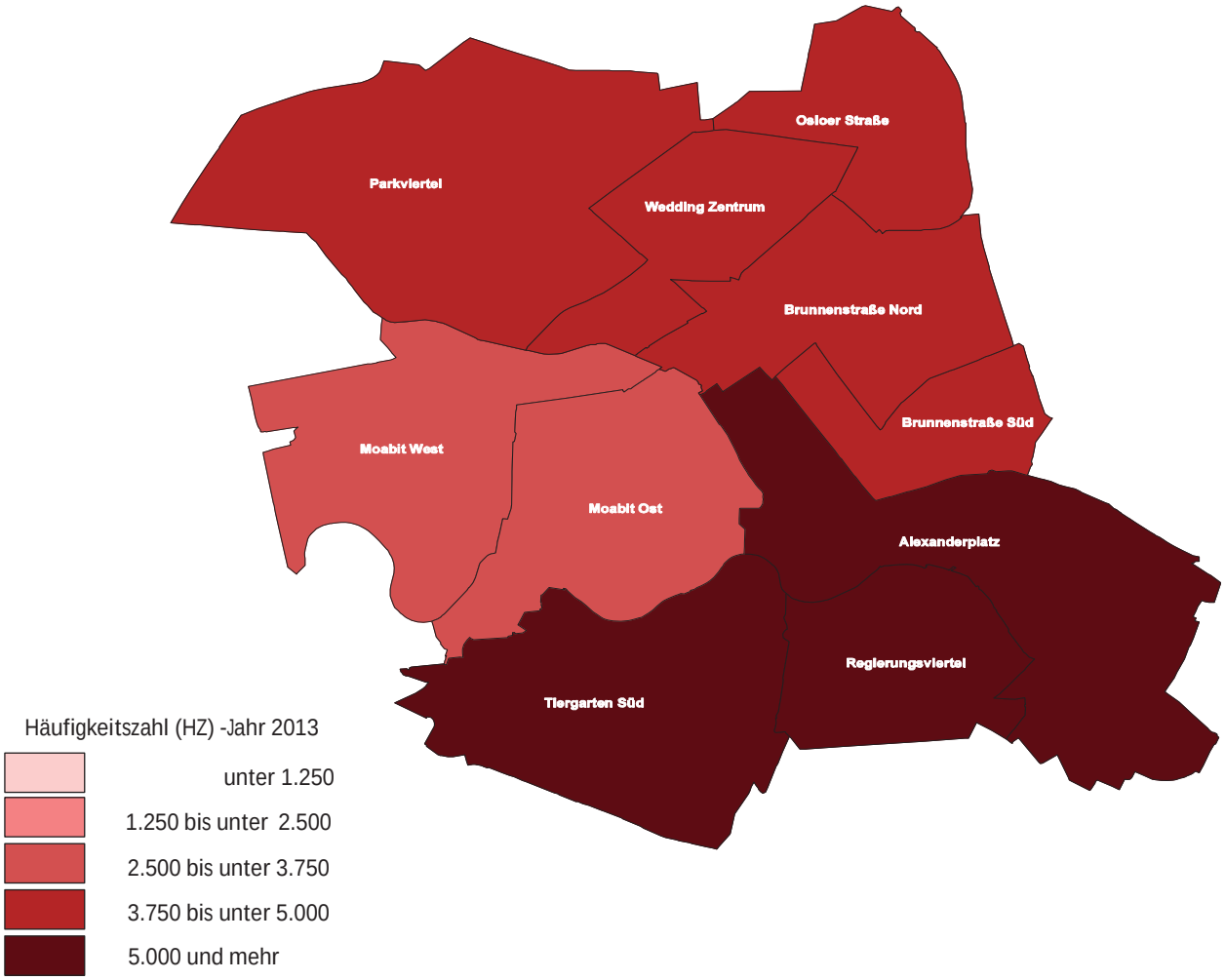

Kiezbezogene Straftaten (Deliktauswahl siehe 'Technische Hinweise')

Bezirksregion	Jahr 2012		Jahr 2013		Zu-/Abnahme			
	erfasste Fälle	HZ	erfasste Fälle	HZ	Fälle		HZ	
					absolut	in %	absolut	in %
Tiergarten Süd.....	1 032	8 190	974	7 487	- 58	- 5,6	- 703	- 8,6
Regierungsviertel.....	870	9 491	862	9 271	- 8	- 0,9	- 220	- 2,3
Alexanderplatz.....	3 108	6 586	3 029	6 293	- 79	- 2,5	- 293	- 4,4
Brunnenstraße Süd.....	752	2 941	1 003	3 776	251	33,4	835	28,4
Moabit West.....	1 403	3 349	1 342	3 138	- 61	- 4,3	- 211	- 6,3
Moabit Ost.....	1 212	3 480	1 188	3 364	- 24	- 2,0	- 116	- 3,3
Osloer Straße.....	1 699	4 848	1 674	4 625	- 25	- 1,5	- 223	- 4,6
Brunnenstraße Nord.....	1 532	4 341	1 597	4 457	65	4,2	116	2,7
Parkviertel.....	1 794	4 329	1 722	4 066	- 72	- 4,0	- 263	- 6,1
Wedding Zentrum.....	2 556	4 865	2 388	4 413	- 168	- 6,6	- 452	- 9,3
nicht zuzuordnen.....	587	-	529	-				

Bezirk Berlin Friedrichshain-Kreuzberg

Kiezbezogene Straftaten (Häufigkeitszahl)

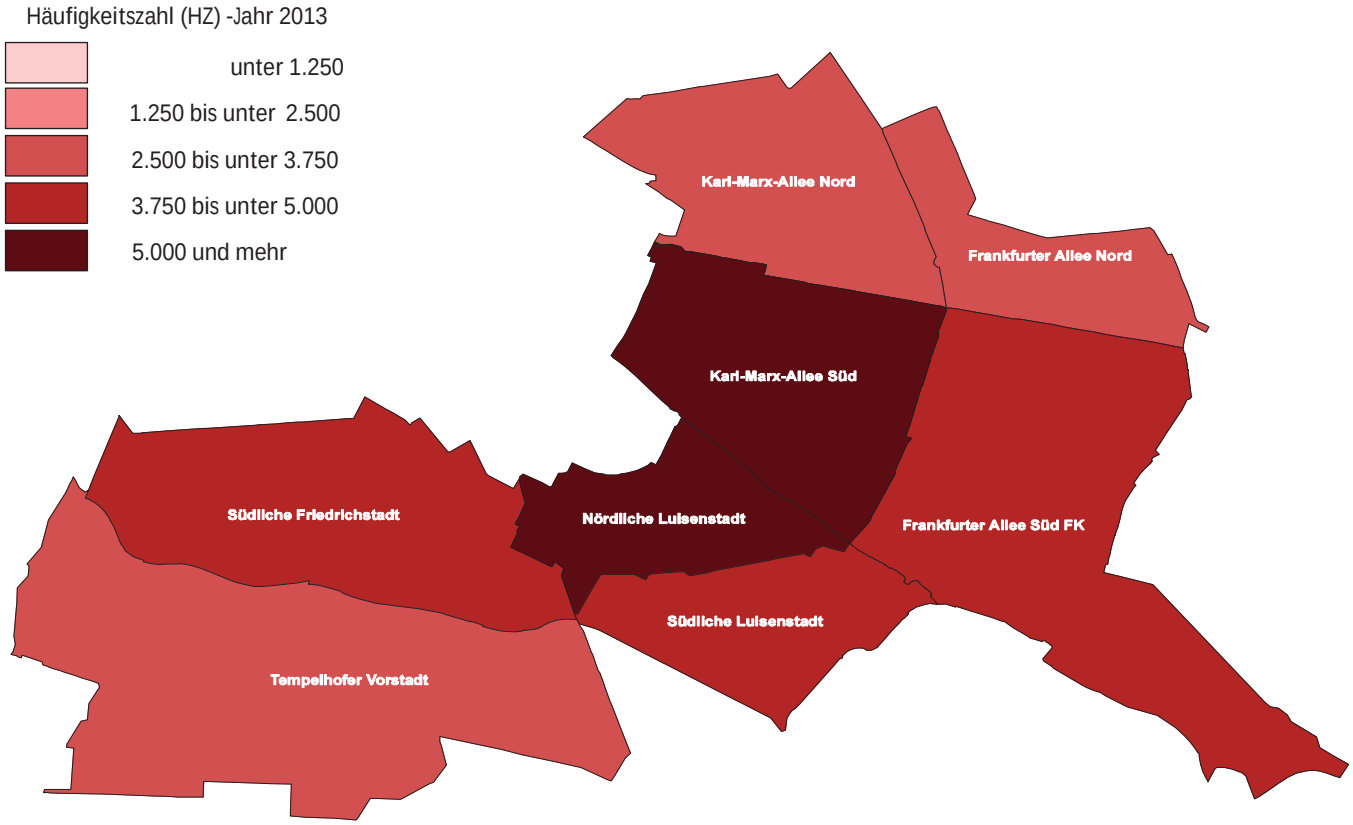

Kiezbezogene Straftaten (Deliktauswahl siehe 'Technische Hinweise')

Bezirksregion	Jahr 2012		Jahr 2013		Zu-/Abnahme			
	erfasste Fälle	HZ	erfasste Fälle	HZ	Fälle		HZ	
					absolut	in %	absolut	in %
Südliche Friedrichstadt.....	1 784	4 580	1 703	4 311	- 81	- 4,5	- 269	- 5,9
Tempelhofer Vorstadt.....	2 271	3 728	2 051	3 311	- 220	- 9,7	- 417	- 11,2
Nördliche Luisenstadt.....	1 115	4 991	1 202	5 331	87	7,8	340	6,8
Südliche Luisenstadt.....	963	3 690	1 239	4 687	276	28,7	997	27,0
Karl-Marx-Allee Nord.....	625	2 808	634	2 820	9	1,4	12	0,4
Karl-Marx-Allee Süd.....	1 040	4 533	1 172	5 006	132	12,7	473	10,4
Frankfurter Allee Nord.....	824	3 034	862	3 123	38	4,6	89	2,9
Frankfurter Allee Süd FK.....	2 086	4 515	2 148	4 545	62	3,0	30	0,7
nicht zuzuordnen.....	293		278					

Bezirk Berlin Pankow

Kiezbezogene Straftaten (Häufigkeitszahl)

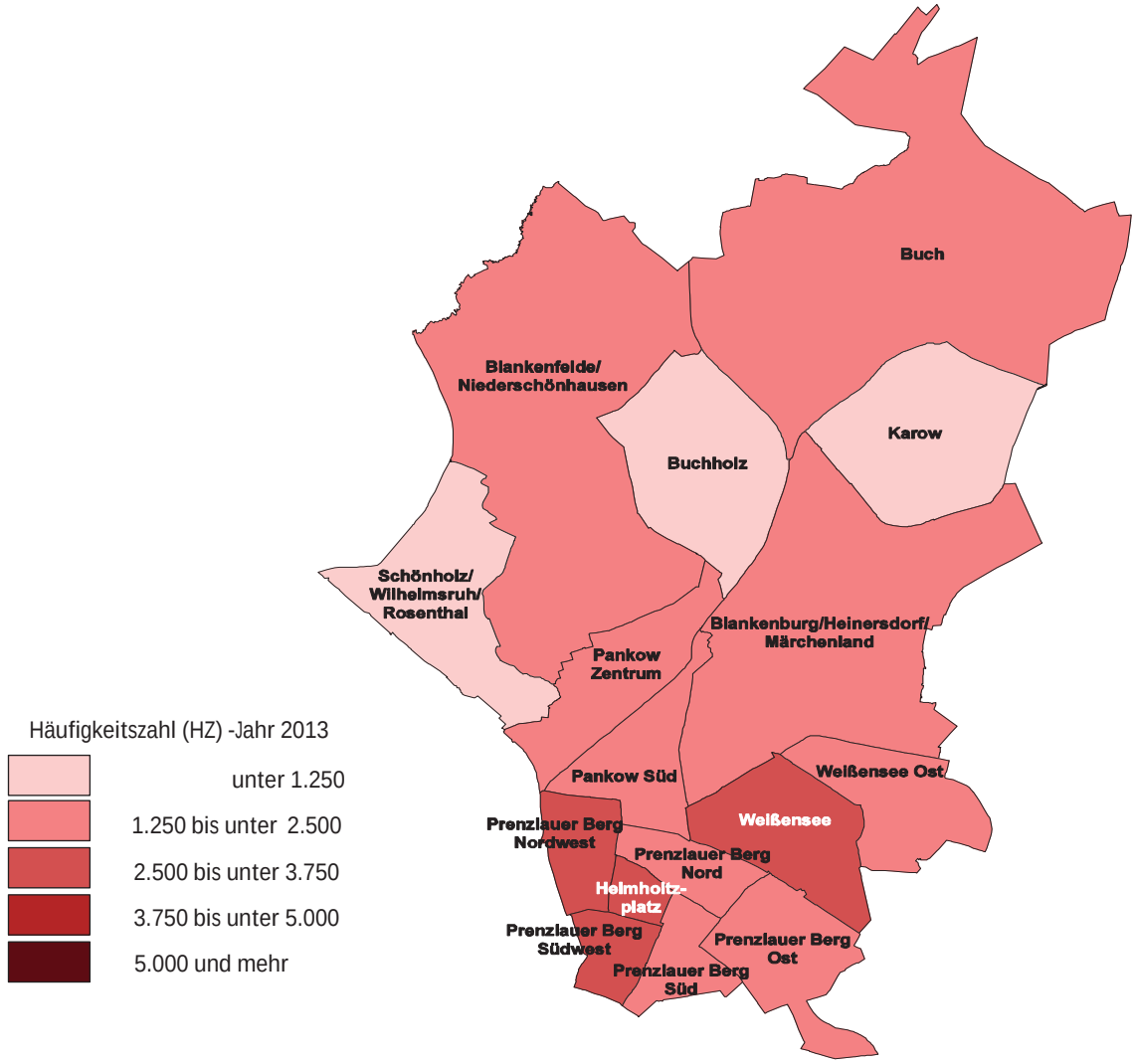

Kiezbezogene Straftaten (Deliktauswahl siehe 'Technische Hinweise')

Bezirksregion	Jahr 2012		Jahr 2013		Zu-/Abnahme			
	erfasste Fälle	HZ	erfasste Fälle	HZ	Fälle absolut	Fälle in %	HZ absolut	HZ in %
Buch	323	2 477	308	2 274	- 15	- 4,6	- 203	- 8,2
Blankenfelde/Niederschönhausen	337	1 331	386	1 485	49	14,5	154	11,6
Buchholz	182	1 084	179	1 054	- 3	- 1,6	- 30	- 2,8
Karow	151	808	206	1 106	55	36,4	298	36,9
Blankenburg/Heinersdorf	161	1 140	197	1 393	36	22,4	253	22,2
Pankow Süd	616	1 935	613	1 888	- 3	- 0,5	- 47	- 2,4
Schönholz/Wilhelmsruh/Rosenthal	229	1 337	193	1 125	- 36	- 15,7	- 212	- 15,9
Pankow Zentrum	811	2 499	776	2 329	- 35	- 4,3	- 170	- 6,8
Weißensee	838	2 544	973	2 895	135	16,1	351	13,8
Weißensee Ost	334	2 226	334	2 207		-	- 19	- 0,9
Prenzlauer Berg Nordwest	766	3 243	683	2 816	- 83	- 10,8	- 427	- 13,2
Prenzlauer Berg Nord	582	2 255	595	2 281	13	2,2	26	1,2
Helmholtzplatz	614	2 896	590	2 723	- 24	- 3,9	- 173	- 6,0
Prenzlauer Berg Ost	714	2 939	619	2 495	- 95	- 13,3	- 444	- 15,1
Prenzlauer Berg Südwest	996	4 109	907	3 656	- 89	- 8,9	- 453	- 11,0
Prenzlauer Berg Süd	672	2 181	686	2 203	14	2,1	22	1,0
nicht zuzuordnen	115		129					

Bezirk Berlin Charlottenburg-Wilmersdorf

Kiezbezogene Straftaten (Häufigkeitszahl)

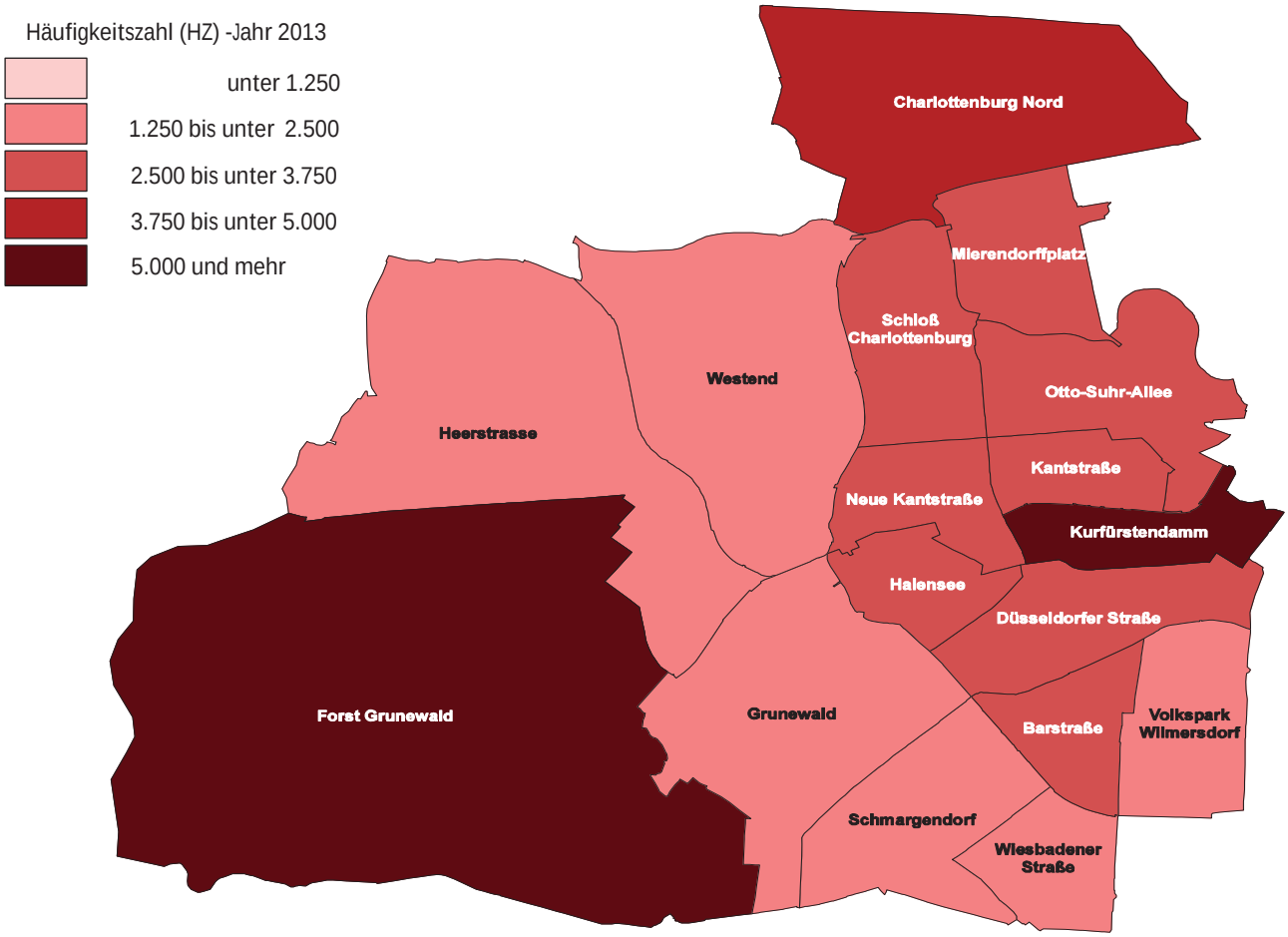

Kiezbezogene Straftaten (Deliktauswahl siehe 'Technische Hinweise')

Bezirksregion	Jahr 2012		Jahr 2013		Zu-/Abnahme			
	erfasste Fälle	HZ	erfasste Fälle	HZ	Fälle absolut	Fälle in %	HZ absolut	HZ in %
Charlottenburg Nord.....	740	4 091	710	3 845	- 30	- 4,1	- 246	- 6,0
Heerstraße.....	353	2 824	273	2 164	- 80	- 22,7	- 660	- 23,4
Westend.....	662	2 529	587	2 203	- 75	- 11,3	- 326	- 12,9
Schloß Charlottenburg.....	616	2 661	633	2 702	17	2,8	41	1,5
Mierendorffplatz.....	413	2 903	466	3 195	53	12,8	292	10,1
Otto-Suhr-Allee.....	952	3 737	965	3 743	13	1,4	6	0,2
Neue Kantstraße.....	560	2 442	723	3 119	163	29,1	677	27,7
Kantstraße.....	691	3 376	695	3 354	4	0,6	- 22	- 0,7
Kurfürstendamm.....	1 685	11 571	1 517	10 400	- 168	- 10,0	- 1 171	- 10,1
Halensee.....	393	2 768	433	3 002	40	10,2	234	8,5
Grunewald.....	391	2 184	414	2 272	23	5,9	88	4,0
Schmargendorf.....	255	1 846	266	1 913	11	4,3	67	3,6
Wiesbadener Straße.....	224	1 243	293	1 622	69	30,8	379	30,5
Düsseldorfer Straße.....	741	2 527	778	2 615	37	5,0	88	3,5
Barstraße.....	302	2 239	378	2 786	76	25,2	547	24,4
Volkspark Wilmersdorf.....	712	2 201	667	2 034	- 45	- 6,3	- 167	- 7,6
Forst Grunewald.....	21		27		6	x		
nicht zuzuordnen.....	286		249					

Bezirk Berlin Spandau

Kiezbezogene Straftaten (Häufigkeitszahl)

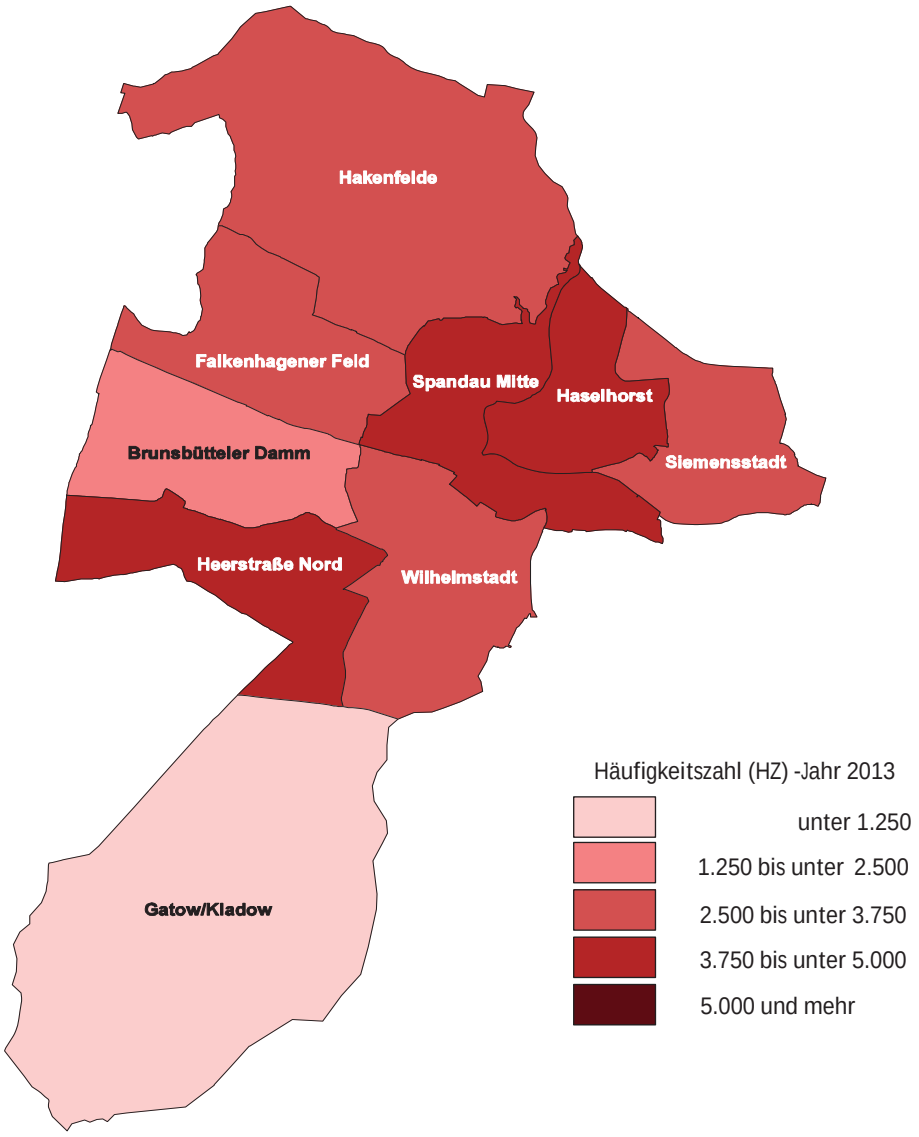

Kiezbezogene Straftaten (Deliktauswahl siehe 'Technische Hinweise')

Bezirksregion	Jahr 2012		Jahr 2013		Zu-/Abnahme			
	erfasste Fälle	HZ	erfasste Fälle	HZ	Fälle absolut	Fälle in %	HZ absolut	HZ in %
Hakenfelde.....	651	2 873	704	3 100	53	8,1	227	7,9
Falkenhagener Feld.....	1 166	2 989	1 135	2 894	- 31	- 2,7	- 95	- 3,2
Spandau Mitte.....	1 607	4 890	1 630	4 836	23	1,4	- 54	- 1,1
Brunsbütteler Damm.....	395	1 706	417	1 804	22	5,6	98	5,7
Heerstraße Nord.....	1 013	3 796	1 031	3 850	18	1,8	54	1,4
Wilhelmstadt.....	1 191	3 515	1 248	3 632	57	4,8	117	3,3
Haselhorst.....	575	4 177	551	3 818	- 24	- 4,2	- 359	- 8,6
Siemensstadt.....	405	3 484	426	3 553	21	5,2	69	2,0
Gatow/Kladow.....	158	889	163	898	5	3,2	9	1,0
nicht zuzuordnen.....	64		59					

Bezirk Berlin Steglitz-Zehlendorf

Kiezbezogene Straftaten (Häufigkeitszahl)

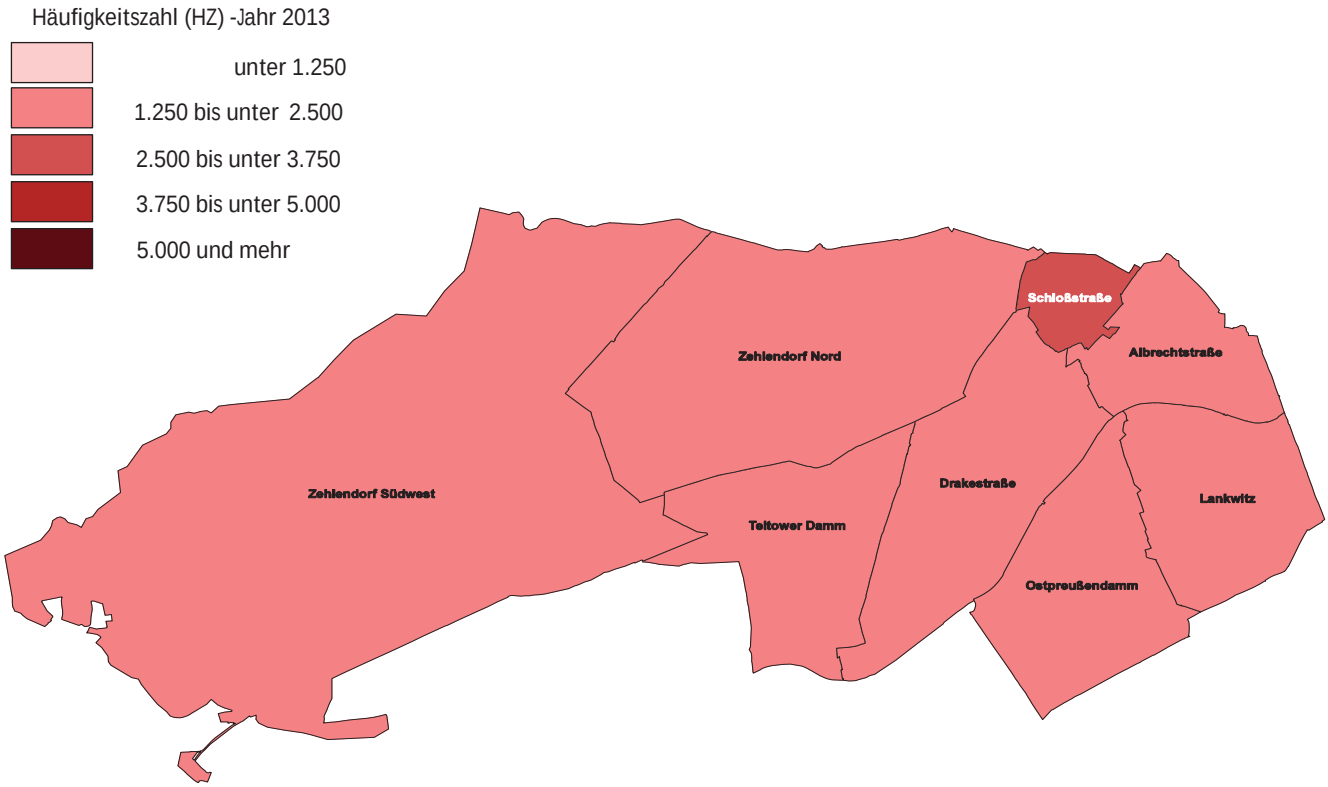

Kiezbezogene Straftaten (Deliktauswahl siehe 'Technische Hinweise')

Bezirksregion	Jahr 2012		Jahr 2013		Zu-/Abnahme			
	erfasste Fälle	HZ	erfasste Fälle	HZ	Fälle		HZ	
					absolut	in %	absolut	in %
Schloßstraße.....	529	2 472	586	2 711	57	10,8	239	9,7
Albrechtstraße.....	832	1 621	879	1 698	47	5,6	77	4,8
Lankwitz.....	748	1 809	784	1 877	36	4,8	68	3,8
Ostpreußendamm.....	482	1 391	549	1 570	67	13,9	179	12,9
Teltower Damm.....	445	1 361	475	1 449	30	6,7	88	6,5
Drakestraße.....	637	1 394	635	1 365	- 2	- 0,3	- 29	- 2,1
Zehlendorf Südwest.....	380	1 489	422	1 652	42	11,1	163	10,9
Zehlendorf Nord.....	701	1 688	610	1 470	- 91	- 13,0	- 218	- 12,9
nicht zuzuordnen.....	64		74					

Bezirk Berlin Tempelhof-Schöneberg

Kiezbezogene Straftaten (Häufigkeitszahl)

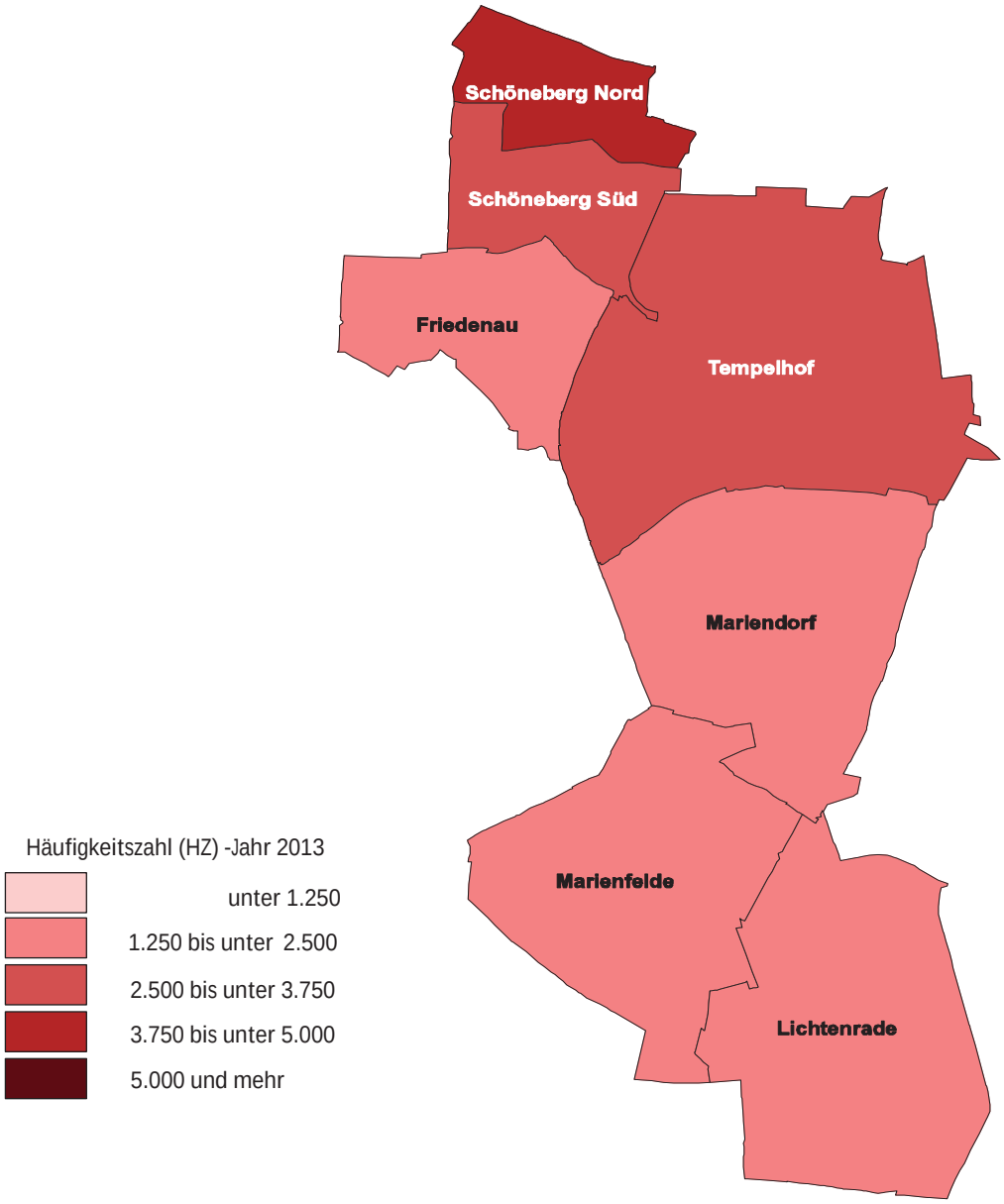

Kiezbezogene Straftaten (Deliktauswahl siehe 'Technische Hinweise')

Bezirksregion	Jahr 2012		Jahr 2013		Zu-/Abnahme			
	erfasste Fälle	HZ	erfasste Fälle	HZ	Fälle		HZ	
					absolut	in %	absolut	in %
Schöneberg Nord.....	1 921	4 078	1 976	4 209	55	2,9	131	3,2
Schöneberg Süd.....	1 297	2 729	1 406	2 949	109	8,4	220	8,1
Friedenau.....	851	1 934	751	1 692	- 100	- 11,8	- 242	- 12,5
Tempelhof.....	1 680	2 850	1 647	2 743	- 33	- 2,0	- 107	- 3,8
Mariendorf.....	1 006	2 019	1 143	2 286	137	13,6	267	13,2
Marienfelde.....	619	2 034	629	2 059	10	1,6	25	1,2
Lichtenrade.....	745	1 507	754	1 517	9	1,2	10	0,7
nicht zuzuordnen.....	144		106					

Bezirk Berlin Neukölln

Kiezbezogene Straftaten (Häufigkeitszahl)

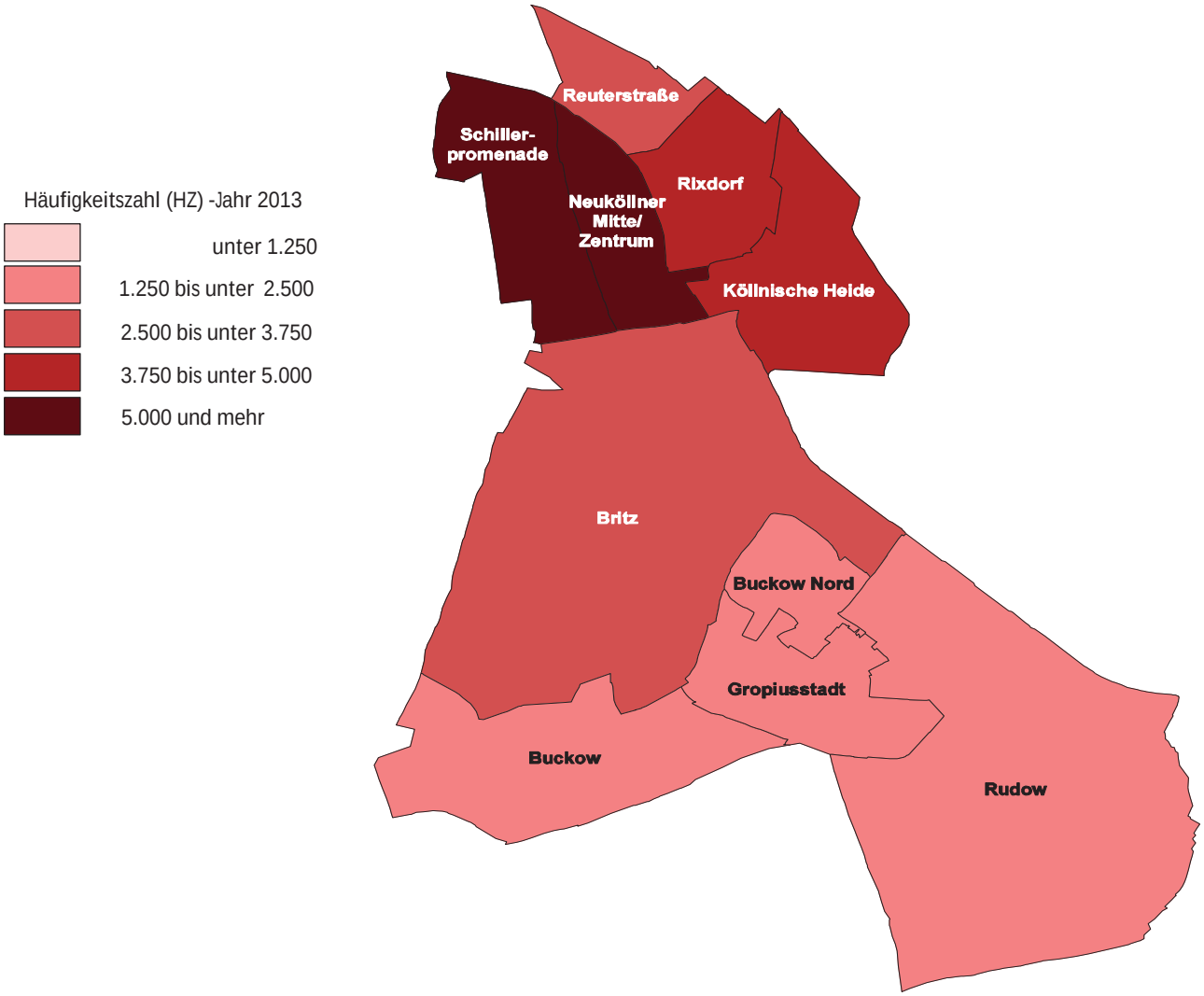

Kiezbezogene Straftaten (Deliktauswahl siehe 'Technische Hinweise')

Bezirksregion	Jahr 2012		Jahr 2013		Zu-/Abnahme			
	erfasste Fälle	HZ	erfasste Fälle	HZ	Fälle absolut	Fälle in %	HZ absolut	HZ in %
Schillerpromenade	1 965	6 354	1 630	5 164	- 335	- 17,0	- 1 190	- 18,7
Neuköllner Mitte/Zentrum	2 164	5 865	2 048	5 427	- 116	- 5,4	- 438	- 7,5
Reuterstraße	1 573	4 051	1 285	3 233	- 288	- 18,3	- 818	- 20,2
Rixdorf	1 542	3 967	1 531	3 873	- 11	- 0,7	- 94	- 2,4
Köllnische Heide	631	4 281	672	4 468	41	6,5	187	4,4
Britz	1 079	2 664	1 188	2 891	109	10,1	227	8,5
Buckow	499	1 807	455	1 634	- 44	- 8,8	- 173	- 9,6
Gropiusstadt	1 070	2 968	834	2 294	- 236	- 22,1	- 674	- 22,7
Buckow Nord	176	1 893	216	2 306	40	22,7	413	21,8
Rudow	543	1 295	570	1 353	27	5,0	58	4,5
nicht zuzuordnen	100		80					

Bezirk Berlin Treptow-Köpenick

Kiezbezogene Straftaten (Häufigkeitszahl)

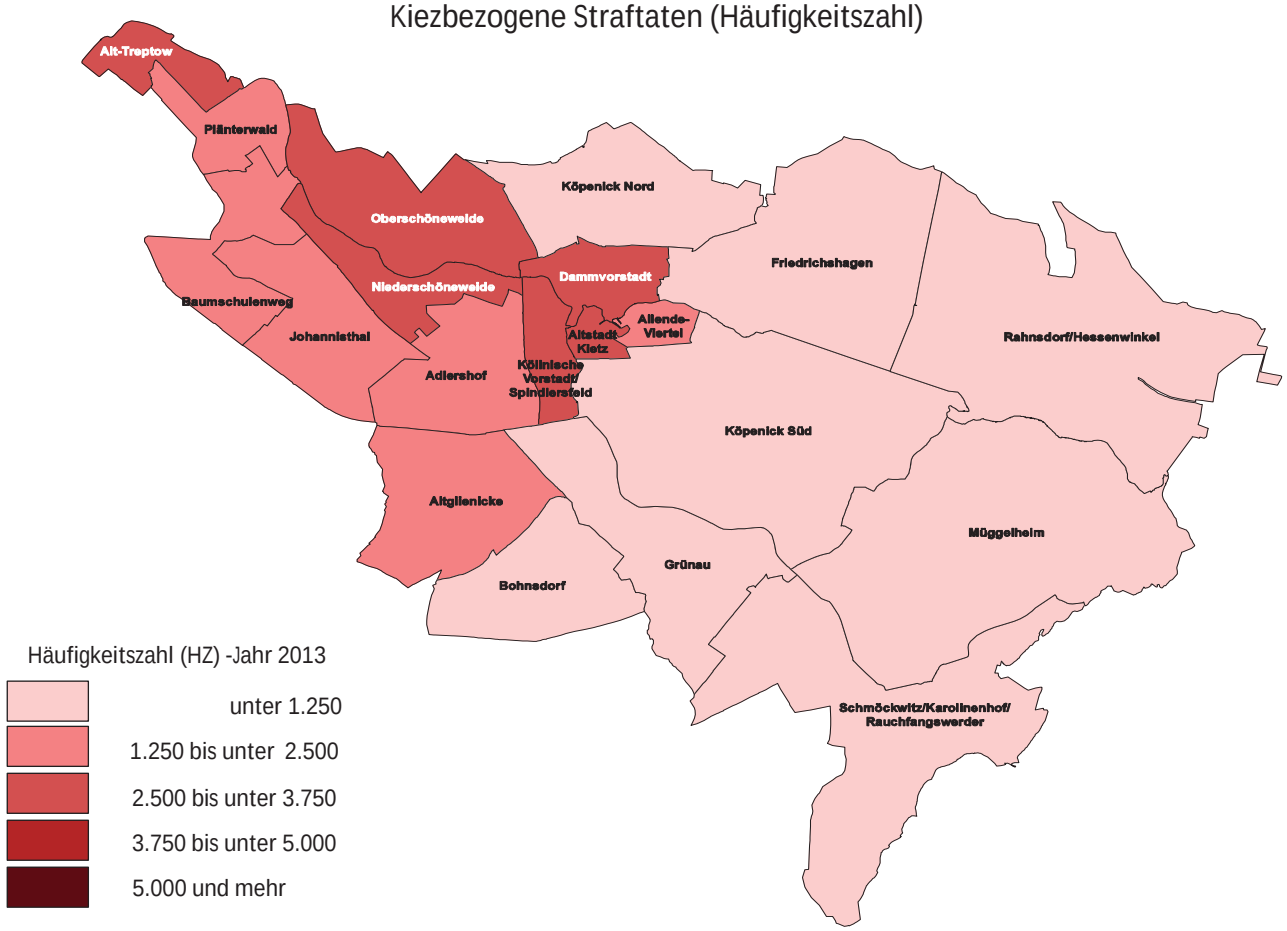

Kiezbezogene Straftaten (Deliktauswahl siehe 'Technische Hinweise')

Bezirksregion	Jahr 2012		Jahr 2013		Zu-/Abnahme			
	erfasste Fälle	HZ	erfasste Fälle	HZ	Fälle absolut	Fälle in %	HZ absolut	HZ in %
Alt-Treptow	376	3 441	343	3 091	- 33	- 8,8	- 350	- 10,2
Plänterwald	243	2 253	241	2 224	- 2	- 0,8	- 29	- 1,3
Baumschulenweg	346	2 008	308	1 767	- 38	- 11,0	- 241	- 12,0
Johannisthal	245	1 337	256	1 389	11	4,5	52	3,9
Oberschöneweide	636	3 319	720	3 652	84	13,2	333	10,0
Niederschöneweide	320	3 062	279	2 624	- 41	- 12,8	- 438	- 14,3
Adlershof	345	2 242	291	1 865	- 54	- 15,7	- 377	- 16,8
Kölln. Vorstadt/Spindlersf.	265	2 692	316	3 158	51	19,2	466	17,3
Altglienicke	311	1 217	332	1 283	21	6,8	66	5,4
Bohnsdorf	134	1 125	138	1 144	4	3,0	19	1,7
Grünau	84	1 556	54	964	- 30	x	- 592	(- 38,0)
Schmöckwitz/Karolinenhof	24	591	43	1 067	19	x	476	(80,5)
Köpenick Süd	174	1 114	186	1 196	12	6,9	82	7,4
Allende-Viertel	100	1 638	97	1 585	- 3	- 3,0	- 53	- 3,2
Altstadt Kietz	173	2 519	199	2 867	26	15,0	348	13,8
Müggelheim	43	661	45	688	2	x	27	(4,1)
Friedrichshagen	173	990	176	1 008	3	1,7	18	1,8
Rahnsdorf/Hessenwinkel	56	625	75	837	19	x	212	(33,9)
Dammvorstadt	244	2 589	322	3 381	78	32,0	792	30,6
Köpenick Nord	118	960	129	1 051	11	9,3	91	9,5
nicht zuzuordnen	161		110					

Bezirk Berlin Marzahn-Hellersdorf

Kiezbezogene Straftaten (Häufigkeitszahl)

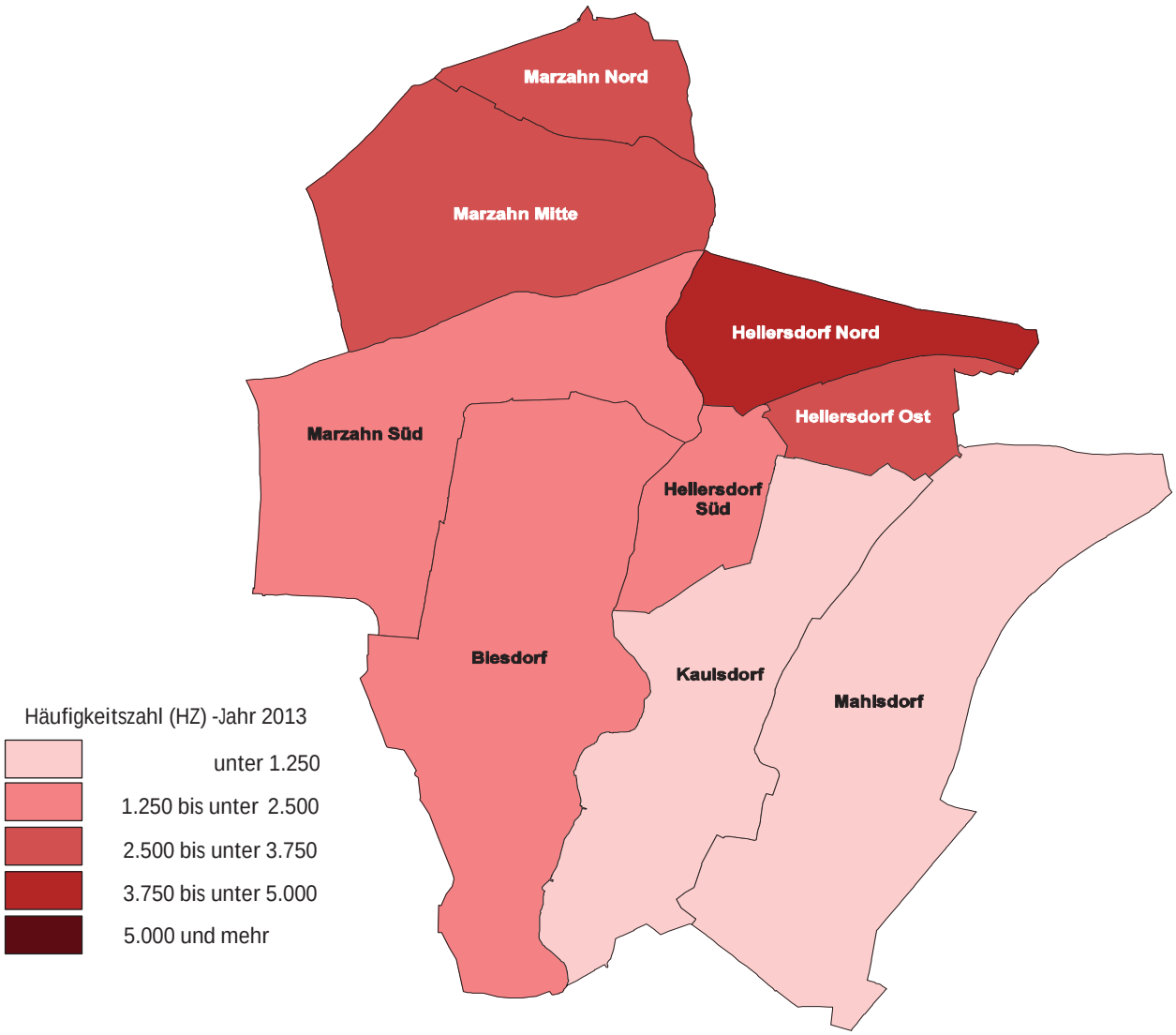

Kiezbezogene Straftaten (Deliktauswahl siehe 'Technische Hinweise')

Bezirksregion	Jahr 2012		Jahr 2013		Zu-/Abnahme			
	erfasste Fälle	HZ	erfasste Fälle	HZ	Fälle absolut	Fälle in %	HZ absolut	HZ in %
Marzahn Nord	811	3 579	780	3 401	- 31	- 3,8	- 178	- 5,0
Marzahn Mitte	1 460	3 231	1 396	3 061	- 64	- 4,4	- 170	- 5,3
Marzahn Süd	648	1 794	818	2 236	170	26,2	442	24,6
Hellersdorf Nord	1 199	3 656	1 357	4 075	158	13,2	419	11,5
Hellersdorf Ost	630	3 415	479	2 537	- 151	- 24,0	- 878	- 25,7
Hellersdorf Süd	541	2 230	595	2 436	54	10,0	206	9,2
Biesdorf	287	1 141	349	1 368	62	21,6	227	19,9
Kaulsdorf	251	1 342	178	954	- 73	- 29,1	- 388	- 28,9
Mahlsdorf	250	926	184	679	- 66	- 26,4	- 247	- 26,7
nicht zuzuordnen	125		94					

Bezirk Berlin Lichtenberg

Kiezbezogene Straftaten (Häufigkeitszahl)

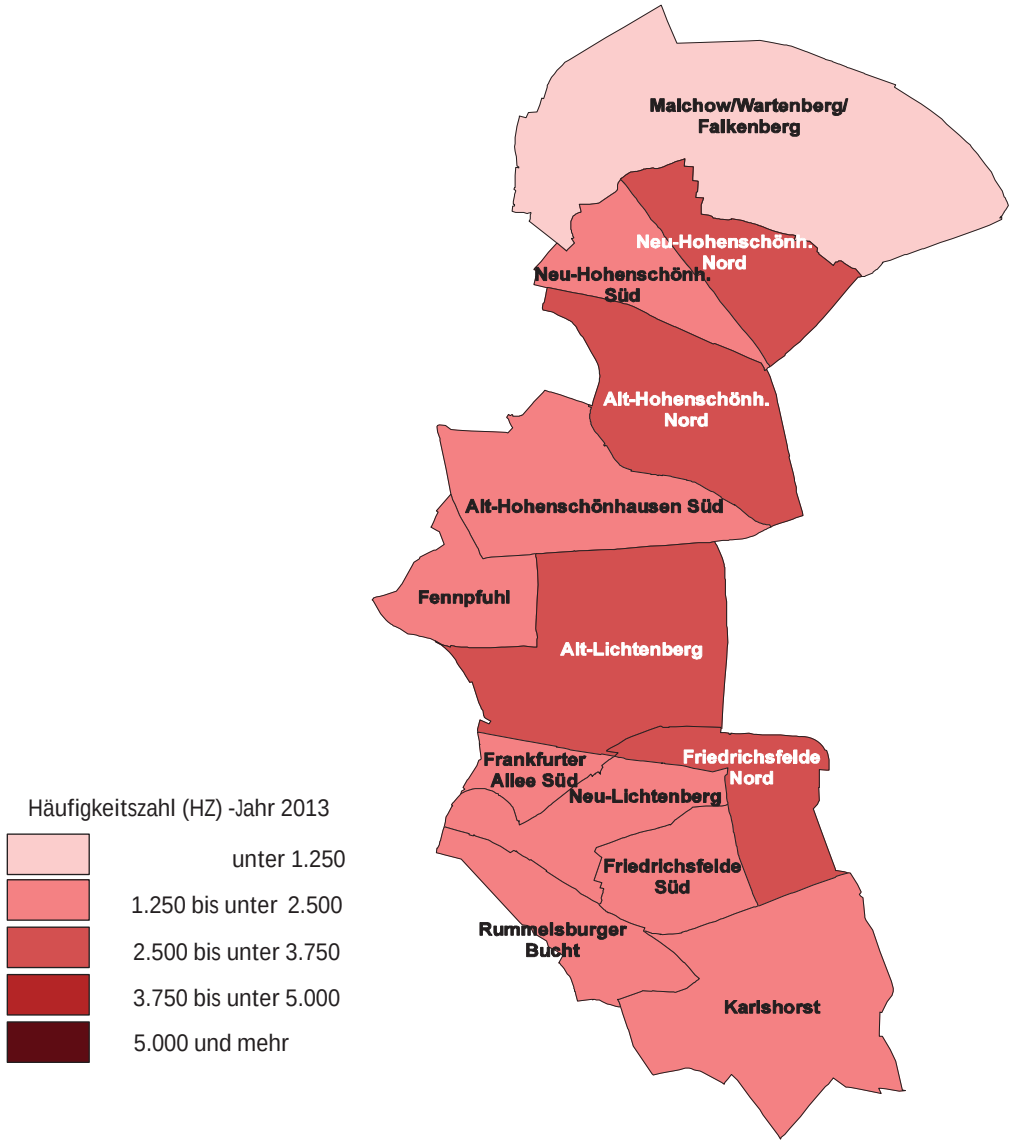

Kiezbezogene Straftaten (Deliktauswahl siehe 'Technische Hinweise')

Bezirksregion	Jahr 2012		Jahr 2013		Zu-/Abnahme			
	erfasste Fälle	HZ	erfasste Fälle	HZ	Fälle absolut	Fälle in %	HZ absolut	HZ in %
Malchow/Warten-/Falkenberg.....	55	1 312	52	1 224	- 3	x	- 88	(- 6,7)
Neu-Hohenschönhausen Nord.....	765	2 783	712	2 572	- 53	- 6,9	- 211	- 7,6
Neu-Hohenschönhausen Süd.....	718	2 775	643	2 487	- 75	- 10,4	- 288	- 10,4
Alt-Hohenschönhausen Nord.....	314	2 331	339	2 513	25	8,0	182	7,8
Alt-Hohenschönhausen Süd.....	647	2 202	731	2 481	84	13,0	279	12,7
Fennpfuhl.....	748	2 358	613	1 915	- 135	- 18,0	- 443	- 18,8
Alt-Lichtenberg.....	818	3 406	874	3 505	56	6,8	99	2,9
Frankfurter Allee Süd.....	200	2 070	237	2 365	37	18,5	295	14,3
Neu-Lichtenberg.....	734	2 499	663	2 207	- 71	- 9,7	- 292	- 11,7
Friedrichsfelde Nord.....	379	2 844	338	2 500	- 41	- 10,8	- 344	- 12,1
Friedrichsfelde Süd.....	402	1 667	403	1 640	1	0,2	- 27	- 1,6
Rummelsburger Bucht.....	60	1 839	62	1 870	2	x	31	(1,7)
Karlshorst.....	273	1 209	351	1 506	78	28,6	297	24,6
nicht zuzuordnen.....	139		84					

Bezirk Berlin Reinickendorf

Kiezbezogene Straftaten (Häufigkeitszahl)

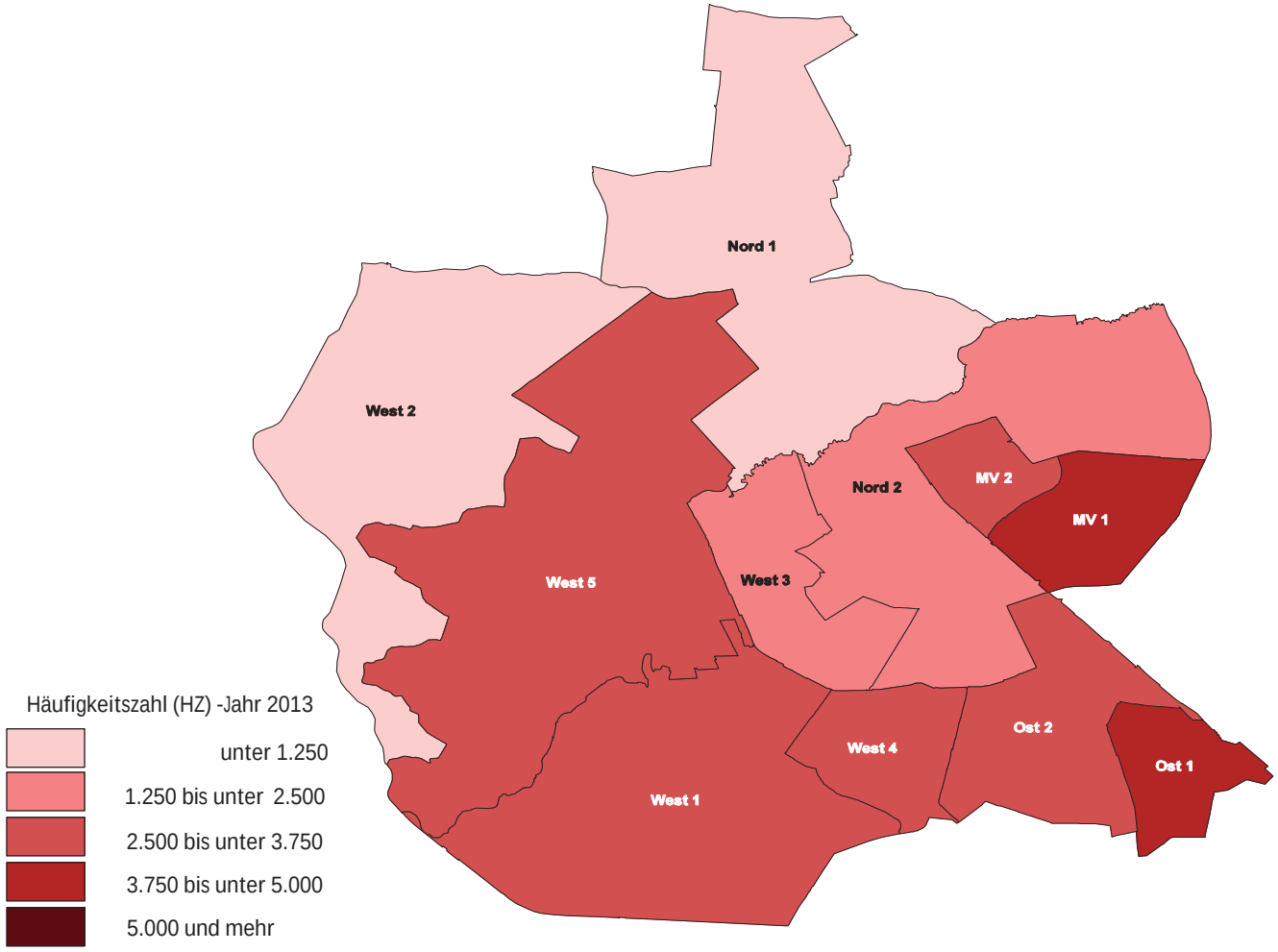

Kiezbezogene Straftaten (Deliktauswahl siehe 'Technische Hinweise')

Bezirksregion	Jahr 2012		Jahr 2013		Zu-/Abnahme			
	erfasste Fälle	HZ	erfasste Fälle	HZ	Fälle		HZ	
					absolut	in %	absolut	in %
Ost 1	939	3 660	979	3 768	40	4,3	108	3,0
Ost 2	721	2 827	789	3 052	68	9,4	225	8,0
West 1	644	4 427	529	3 656	- 115	- 17,9	- 771	- 17,4
West 4	867	3 469	850	3 344	- 17	- 2,0	- 125	- 3,6
West 5	434	4 248	336	3 264	- 98	- 22,6	- 984	- 23,2
West 2	284	1 205	279	1 173	- 5	- 1,8	- 32	- 2,7
Nord 1	340	1 040	334	1 018	- 6	- 1,8	- 22	- 2,1
Nord 2	672	2 302	662	2 224	- 10	- 1,5	- 78	- 3,4
MV 1	1 306	3 687	1 486	4 085	180	13,8	398	10,8
MV 2	229	2 795	223	2 623	- 6	- 2,6	- 172	- 6,2
West 3	328	2 053	272	1 701	- 56	- 17,1	- 352	- 17,1
nicht zuzuordnen	51		41					

Berlin - Raub (Häufigkeitszahl)

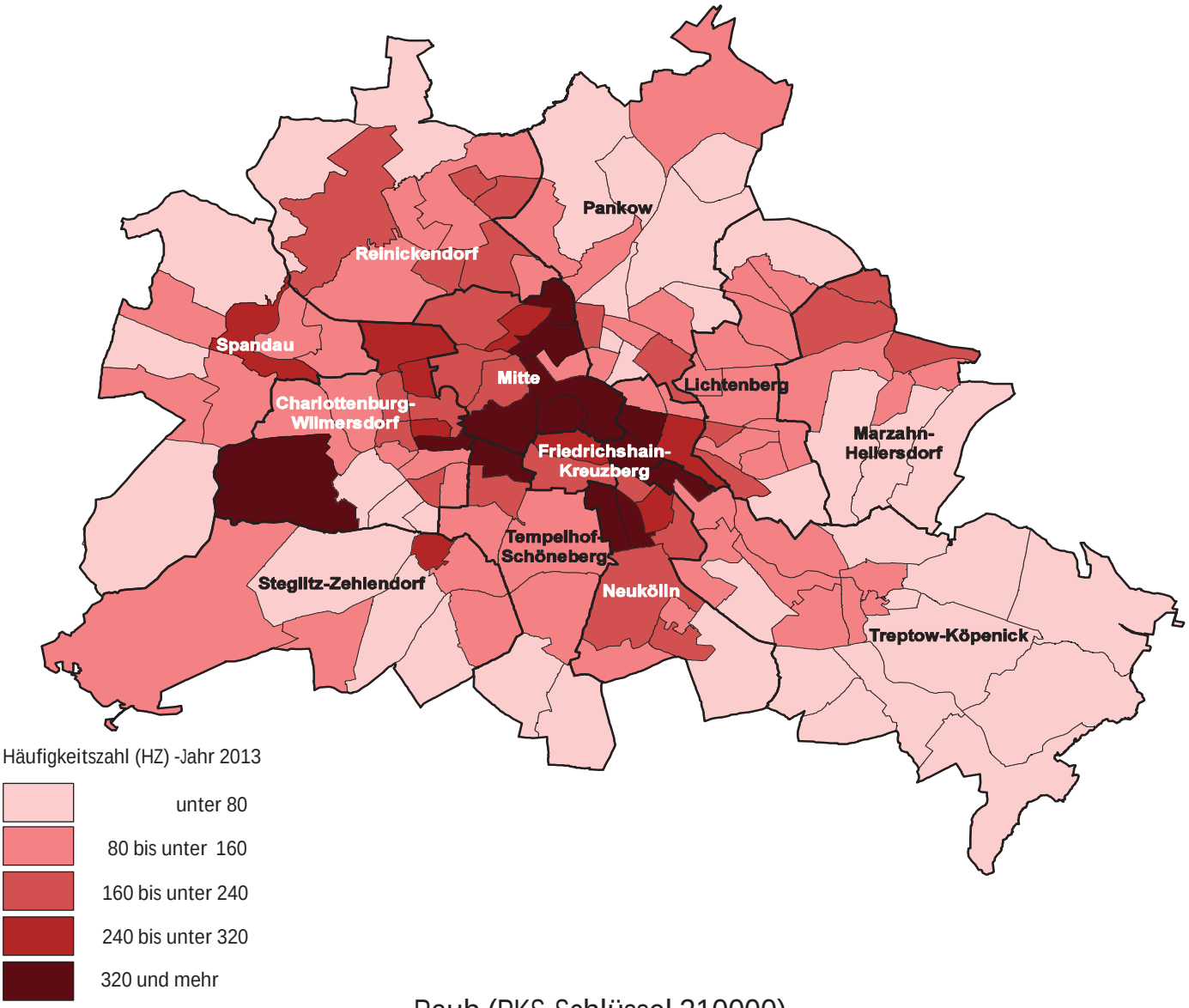

Raub (PKS-Schlüssel 210000)

Bezirk	Jahr 2012		Jahr 2013		Zu-/Abnahme			
	erfasste Fälle	HZ	erfasste Fälle	HZ	Fälle absolut	Fälle in %	HZ absolut	HZ in %
Mitte	1 253	373	1 096	319	- 157	- 12,5	- 54	- 14,5
Friedrichshain-Kreuzberg	868	325	906	334	38	4,4	9	2,8
Pankow	410	112	332	89	- 78	- 19,0	- 23	- 20,5
Charlottenburg-Wilmersdorf	643	203	639	199	- 4	- 0,6	- 4	- 2,0
Spandau	359	162	295	131	- 64	- 17,8	- 31	- 19,1
Steglitz-Zehlendorf	284	97	288	97	4	1,4	-	-
Tempelhof-Schöneberg	546	167	600	182	54	9,9	15	9,0
Neukölln	767	243	752	235	- 15	- 2,0	- 8	- 3,3
Treptow-Köpenick	225	93	209	85	- 16	- 7,1	- 8	- 8,6
Marzahn-Hellersdorf	331	132	327	129	- 4	- 1,2	- 3	- 2,3
Lichtenberg	260	101	282	107	22	8,5	6	5,9
Reinickendorf	337	137	362	145	25	7,4	8	5,8
Berlin, nicht zuzuordnen	136		134					
Berlin -Gesamt-	**6 419**	**190**	**6 222**	**183**	**- 197**	**-3,1**	**- 8**	**-4,0**

Bezirk Berlin Mitte

Raub (Häufigkeitszahl)

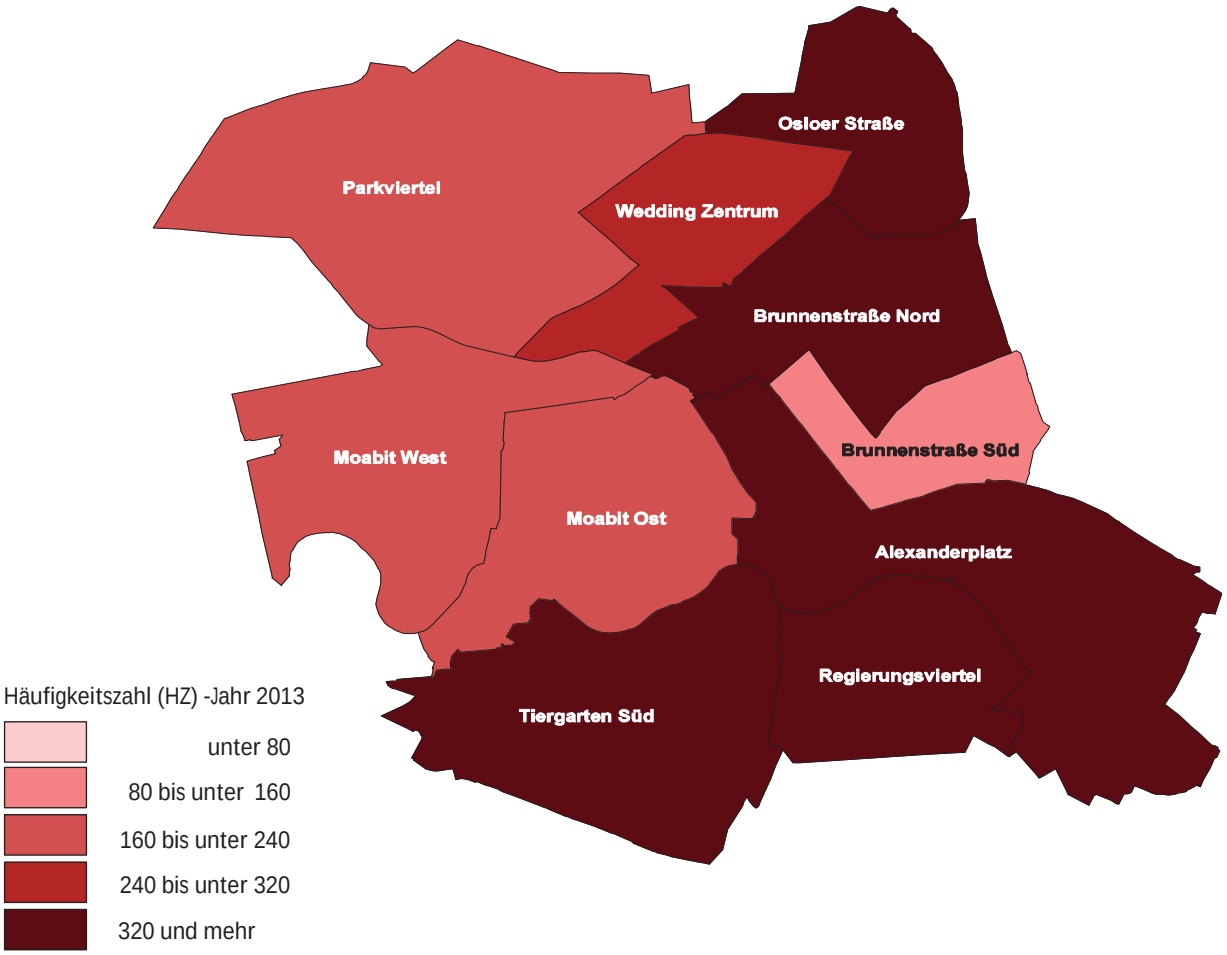

Raub (PKS-Schlüssel 210000)

Bezirksregion	Jahr 2012		Jahr 2013		Zu-/Abnahme			
	erfasste Fälle	HZ	erfasste Fälle	HZ	Fälle absolut	Fälle in %	HZ absolut	HZ in %
Tiergarten Süd	70	556	88	676	18	x	120	(21,6)
Regierungsviertel	65	709	53	570	- 12	x	- 139	(-19,6)
Alexanderplatz	242	513	237	492	- 5	- 2,1	- 21	- 4,1
Brunnenstraße Süd	52	203	41	154	- 11	x	- 49	(-24,1)
Moabit West	130	310	94	220	- 36	- 27,7	- 90	- 29,0
Moabit Ost	89	256	76	215	- 13	x	- 41	(-16,0)
Osloer Straße	120	342	125	345	5	4,2	3	0,9
Brunnenstraße Nord	145	411	126	352	- 19	- 13,1	- 59	- 14,4
Parkviertel	109	263	87	205	- 22	- 20,2	- 58	- 22,1
Wedding Zentrum	216	411	160	296	- 56	- 25,9	- 115	- 28,0
nicht zuzuordnen	15	-	9	-				

Bezirk Berlin Friedrichshain-Kreuzberg

Raub (Häufigkeitszahl)

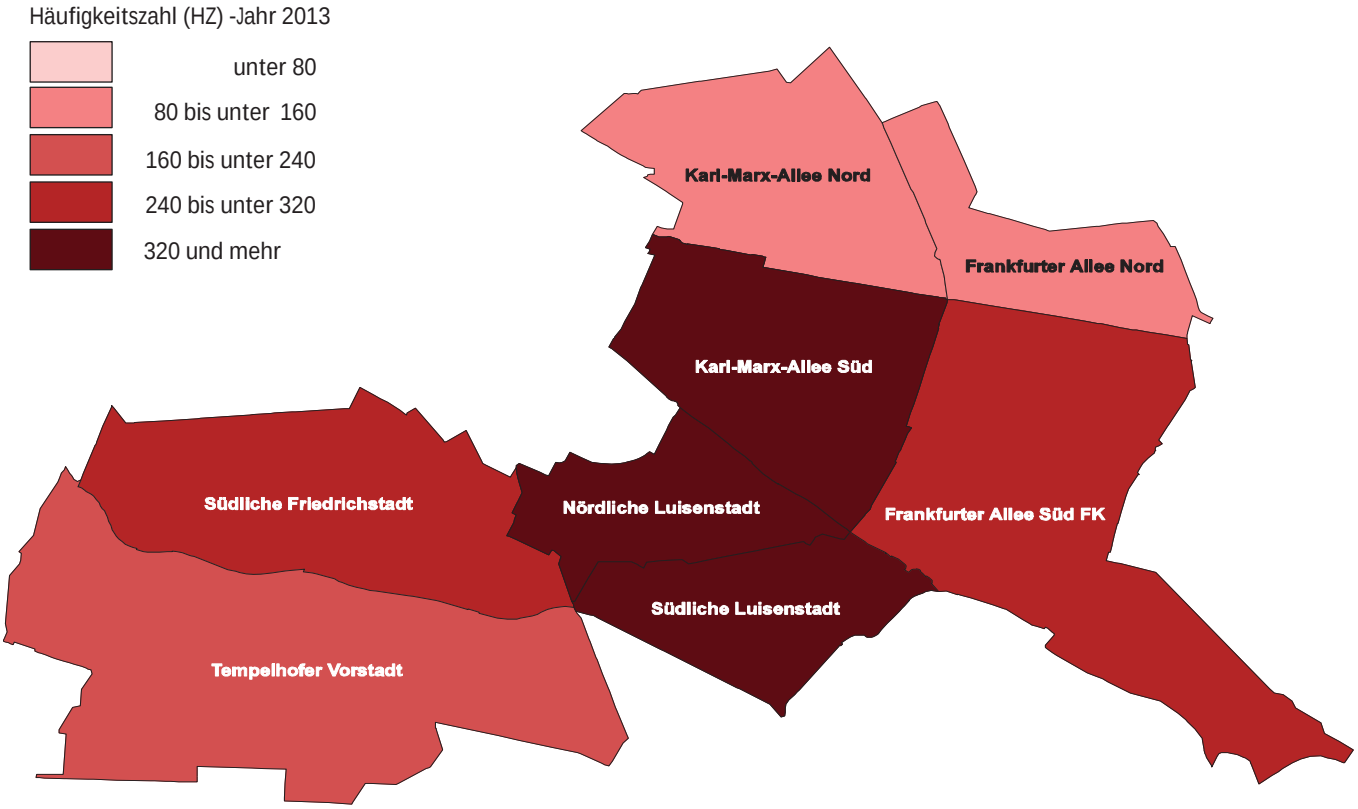

Raub (PKS-Schlüssel 210000)

Bezirksregion	Jahr 2012		Jahr 2013		Zu-/Abnahme			
	erfasste Fälle	HZ	erfasste Fälle	HZ	Fälle absolut	Fälle in %	HZ absolut	HZ in %
Südliche Friedrichstadt.....	138	354	125	316	- 13	- 9,4	- 38	- 10,7
Tempelhofer Vorstadt.....	180	295	143	231	- 37	- 20,6	- 64	- 21,7
Nördliche Luisenstadt.....	112	501	140	621	28	25,0	120	24,0
Südliche Luisenstadt.....	109	418	210	794	101	92,7	376	90,0
Karl-Marx-Allee Nord.....	58	261	31	138	- 27	x	- 123	(- 47,1)
Karl-Marx-Allee Süd.....	86	375	87	372	1	x	- 3	(- 0,8)
Frankfurter Allee Nord.....	34	125	33	120	- 1	x	- 5	(- 4,0)
Frankfurter Allee Süd FK.....	140	303	124	262	- 16	- 11,4	- 41	- 13,5
nicht zuzuordnen.....	11		13					

Bezirk Berlin Pankow

Raub (Häufigkeitszahl)

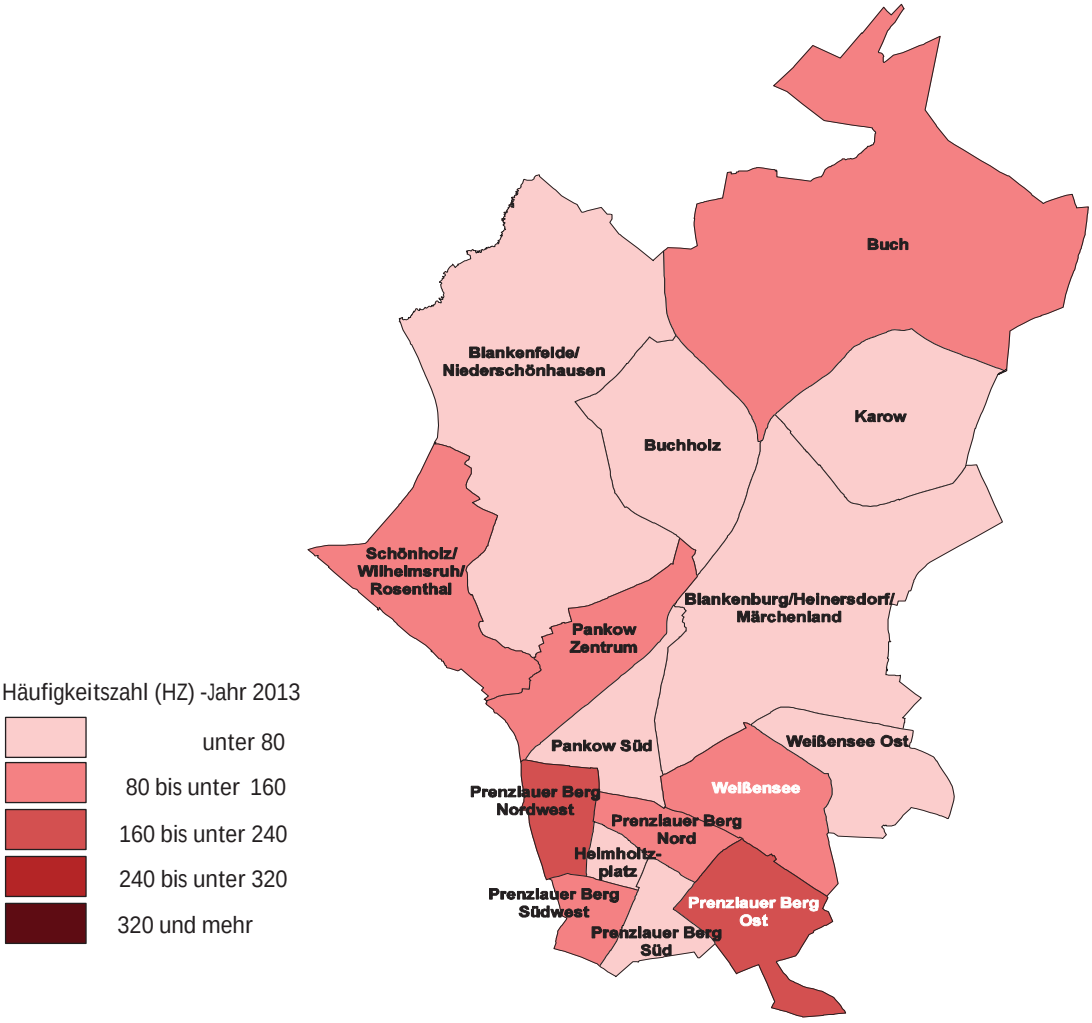

Raub (PKS-Schlüssel 210000)

Bezirksregion	Jahr 2012		Jahr 2013		Zu-/Abnahme			
	erfasste Fälle	HZ	erfasste Fälle	HZ	Fälle absolut	Fälle in %	HZ absolut	HZ in %
Buch	16	123	12	89	- 4	x	- 34	(- 27,6)
Blankenfelde/Niederschönhausen	12	47	16	62	4	x	15	x
Buchholz	9	54	3	18	- 6	x	- 36	x
Karow	3	16	4	21	1	x	5	x
Blankenburg/Heinersdorf	7	50	6	42	- 1	x	- 8	x
Pankow Süd	21	66	16	49	- 5	x	- 17	x
Schönholz/Wilhelmsruh/Rosenthal	23	134	15	87	- 8	x	- 47	(- 35,1)
Pankow Zentrum	33	102	37	111	4	x	9	(8,8)
Weißensee	34	103	28	83	- 6	x	- 20	(- 19,4)
Weißensee Ost	20	133	11	73	- 9	x	- 60	(- 45,1)
Prenzlauer Berg Nordwest	80	339	51	210	- 29	x	- 129	(- 38,1)
Prenzlauer Berg Nord	30	116	21	80	- 9	x	- 36	(- 31,0)
Helmholtzplatz	23	108	14	65	- 9	x	- 43	(- 39,8)
Prenzlauer Berg Ost	60	247	43	173	- 17	x	- 74	(- 30,0)
Prenzlauer Berg Südwest	18	74	29	117	11	x	43	x
Prenzlauer Berg Süd	16	52	17	55	1	x	3	x
nicht zuzuordnen	5		9					

Bezirk Berlin Charlottenburg-Wilmersdorf

Raub (Häufigkeitszahl)

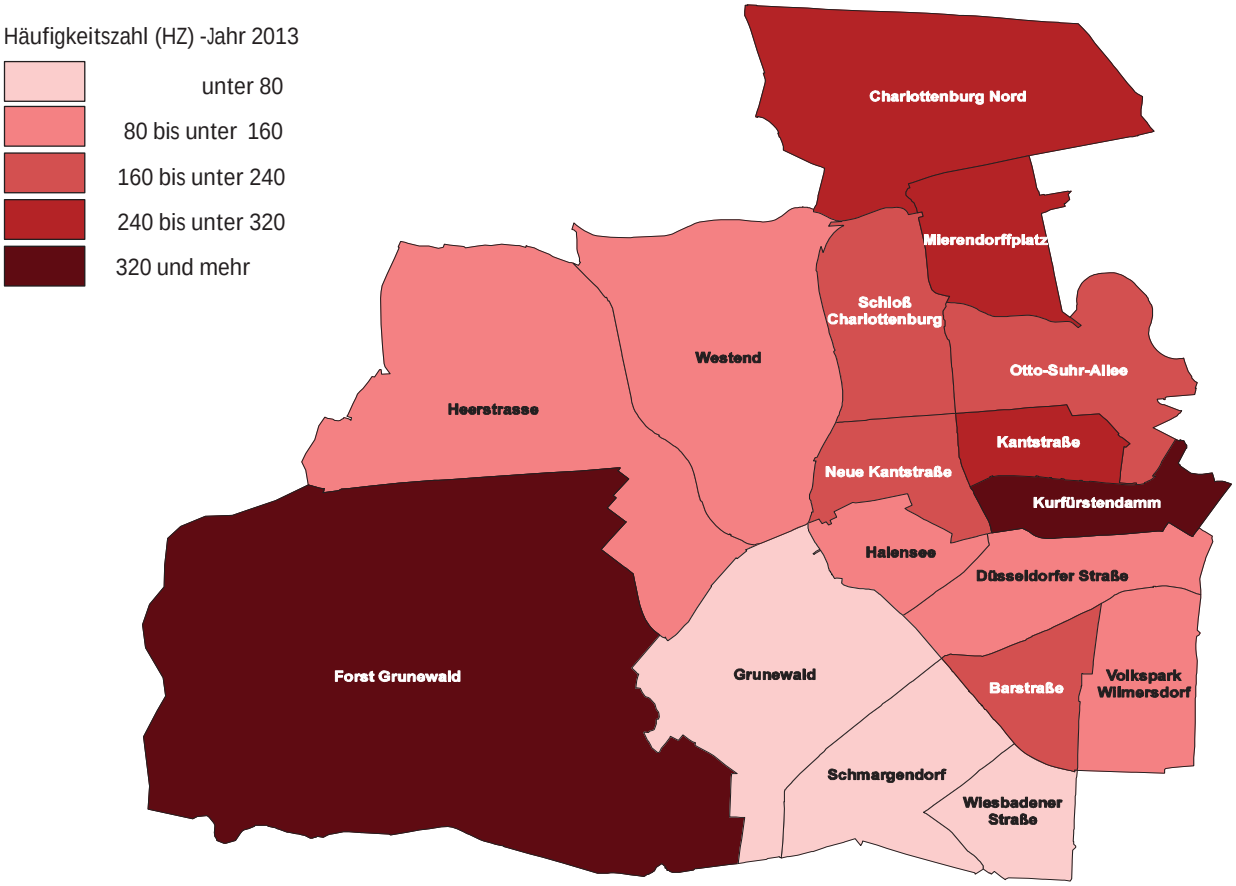

Raub (PKS-Schlüssel 210000)

Bezirksregion	Jahr 2012		Jahr 2013		Zu-/Abnahme			
	erfasste Fälle	HZ	erfasste Fälle	HZ	Fälle absolut	Fälle in %	HZ absolut	HZ in %
Charlottenburg Nord.....	41	227	53	287	12	x	60	(26,4)
Heerstraße.....	21	168	19	151	- 2	x	- 17	(- 10,1)
Westend.....	40	153	31	116	- 9	x	- 37	(- 24,2)
Schloß Charlottenburg.....	41	177	46	196	5	x	19	(10,7)
Mierendorffplatz.....	32	225	40	274	8	x	49	(21,8)
Otto-Suhr-Allee.....	53	208	60	233	7	x	25	(12,0)
Neue Kantstraße.....	43	188	46	198	3	x	10	(5,3)
Kantstraße.....	65	318	60	290	- 5	x	- 28	(- 8,8)
Kurfürstendamm.....	135	927	112	768	- 23	- 17,0	- 159	- 17,2
Halensee.....	19	134	23	159	4	x	25	(18,7)
Grunewald.....	10	56	13	71	3	x	15	x
Schmargendorf.....	5	36	11	79	6	x	43	x
Wiesbadener Straße.....	12	67	12	66		x	- 1	x
Düsseldorfer Straße.....	41	140	37	124	- 4	x	- 16	(- 11,4)
Barstraße.....	19	141	23	169	4	x	28	(19,9)
Volkspark Wilmersdorf.....	64	198	51	155	- 13	x	- 43	(- 21,7)
Forst Grunewald.....	1		1			x		
nicht zuzuordnen.....	1		1					

Bezirk Berlin Spandau

Raub (Häufigkeitszahl)

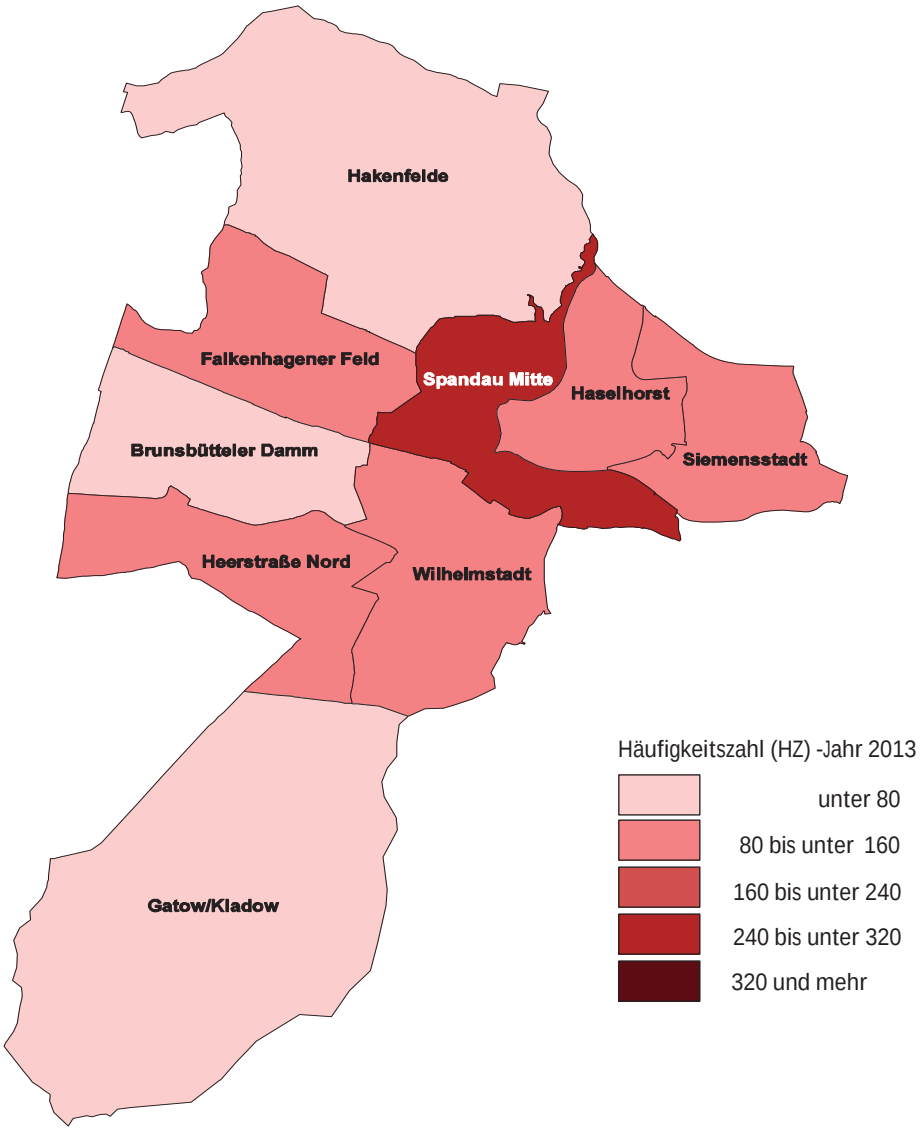

Raub (PKS-Schlüssel 210000)

Bezirksregion	Jahr 2012		Jahr 2013		Zu-/Abnahme			
	erfasste Fälle	HZ	erfasste Fälle	HZ	Fälle absolut	Fälle in %	HZ absolut	HZ in %
Hakenfelde.....	17	75	14	62	- 3	x	- 13	x
Falkenhagener Feld.....	40	103	52	133	12	x	30	(29,1)
Spandau Mitte.....	108	329	96	285	- 12	- 11,1	- 44	- 13,4
Brunsbütteler Damm.....	14	60	16	69	2	x	9	x
Heerstraße Nord.....	41	154	29	108	- 12	x	- 46	(- 29,9)
Wilhelmstadt.....	68	201	43	125	- 25	x	- 76	(- 37,8)
Haselhorst.....	36	261	20	139	- 16	x	- 122	(- 46,7)
Siemensstadt.....	29	249	19	158	- 10	x	- 91	(- 36,5)
Gatow/Kladow.....	5	28	4	22	- 1	x	- 6	x
nicht zuzuordnen.....	1		2					

Bezirk Berlin Steglitz-Zehlendorf

Raub (Häufigkeitszahl)

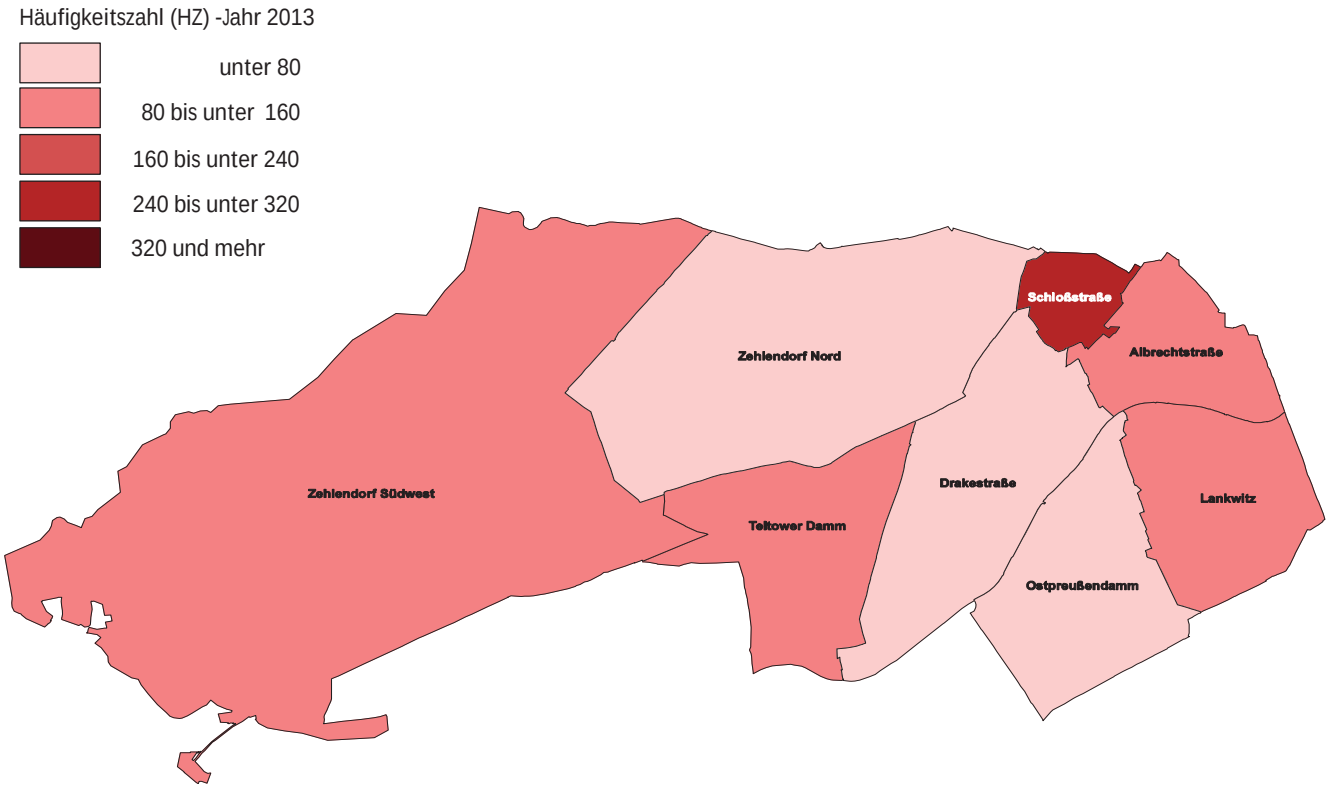

Raub (PKS-Schlüssel 210000)

Bezirksregion	Jahr 2012		Jahr 2013		Zu-/Abnahme			
	erfasste Fälle	HZ	erfasste Fälle	HZ	Fälle absolut	Fälle in %	HZ absolut	HZ in %
Schloßstraße.....	61	285	67	310	6	x	25	(8,8)
Albrechtstraße.....	57	111	54	104	- 3	x	- 7	(- 6,3)
Lankwitz.....	36	87	34	81	- 2	x	- 6	x
Ostpreußendamm.....	17	49	19	54	2	x	5	x
Teltower Damm.....	23	70	35	107	12	x	37	x
Drakestraße.....	18	39	30	64	12	x	25	x
Zehlendorf Südwest.....	27	106	21	82	- 6	x	- 24	(- 22,6)
Zehlendorf Nord.....	44	106	27	65	- 17	x	- 41	(- 38,7)
nicht zuzuordnen.....	1		1					

Bezirk Berlin Tempelhof-Schöneberg

Raub (Häufigkeitszahl)

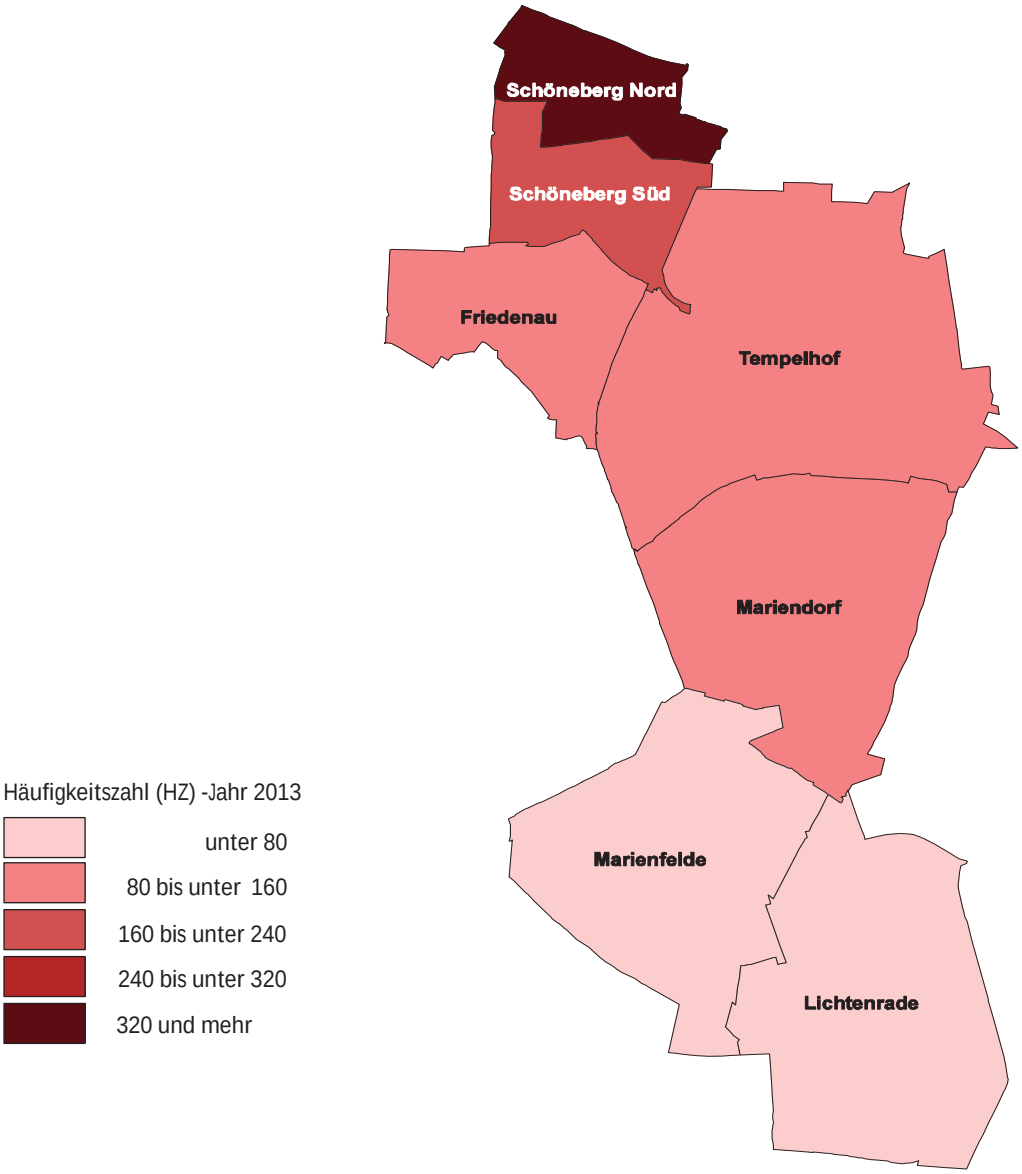

Raub (PKS-Schlüssel 210000)

Bezirksregion	Jahr 2012		Jahr 2013		Zu-/Abnahme			
	erfasste Fälle	HZ	erfasste Fälle	HZ	Fälle absolut	Fälle in %	HZ absolut	HZ in %
Schöneberg Nord.....	197	418	241	513	44	22,3	95	22,7
Schöneberg Süd.....	80	168	93	195	13	x	27	(16,1)
Friedenau.....	44	100	62	140	18	x	40	(40,0)
Tempelhof.....	100	170	88	147	- 12	- 12,0	- 23	- 13,5
Mariendorf.....	57	114	60	120	3	x	6	(5,3)
Marienfelde.....	25	82	23	75	- 2	x	- 7	x
Lichtenrade.....	38	77	31	62	- 7	x	- 15	x
nicht zuzuordnen.....	5		2					

Bezirk Berlin Neukölln

Raub (Häufigkeitszahl)

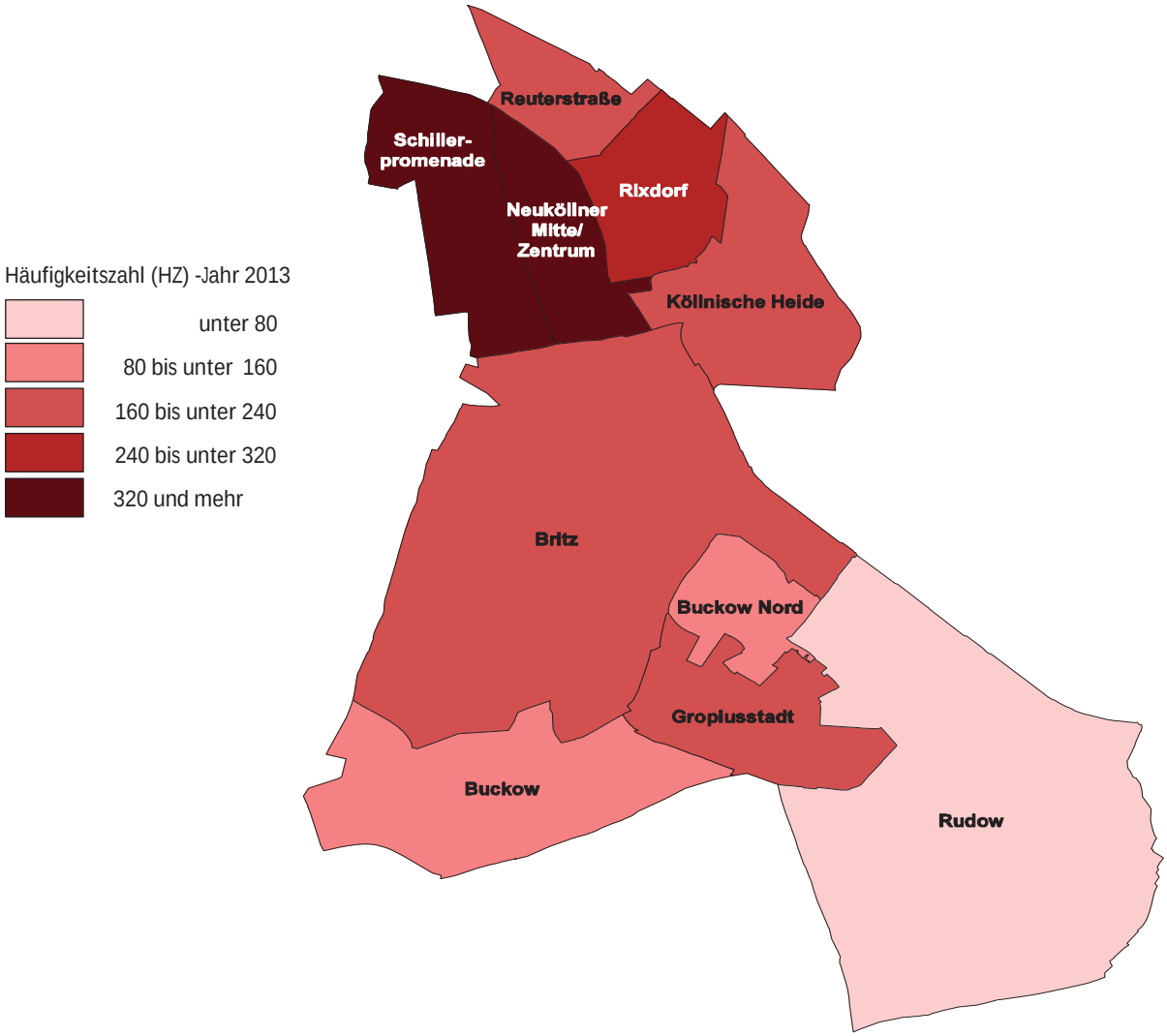

Raub (PKS-Schlüssel 210000)

Bezirksregion	Jahr 2012		Jahr 2013		Zu-/Abnahme			
	erfasste Fälle	HZ	erfasste Fälle	HZ	Fälle absolut	Fälle in %	HZ absolut	HZ in %
Schillerpromenade.....	169	546	144	456	- 25	- 14,8	- 90	- 16,5
Neuköllner Mitte/Zentrum.....	138	374	135	358	- 3	- 2,2	- 16	- 4,3
Reuterstraße.....	108	278	95	239	- 13	- 12,0	- 39	- 14,0
Rixdorf.....	113	291	125	316	12	10,6	25	8,6
Köllnische Heide.....	26	176	30	199	4	x	23	(13,1)
Britz.....	79	195	75	183	- 4	x	- 12	(- 6,2)
Buckow.....	26	94	24	86	- 2	x	- 8	x
Gropiusstadt.....	52	144	76	209	24	x	65	(45,1)
Buckow Nord.....	14	151	11	117	- 3	x	- 34	(- 22,5)
Rudow.....	40	95	32	76	- 8	x	- 19	x
nicht zuzuordnen.....	2		5					

Bezirk Berlin Treptow-Köpenick

Raub (Häufigkeitszahl)

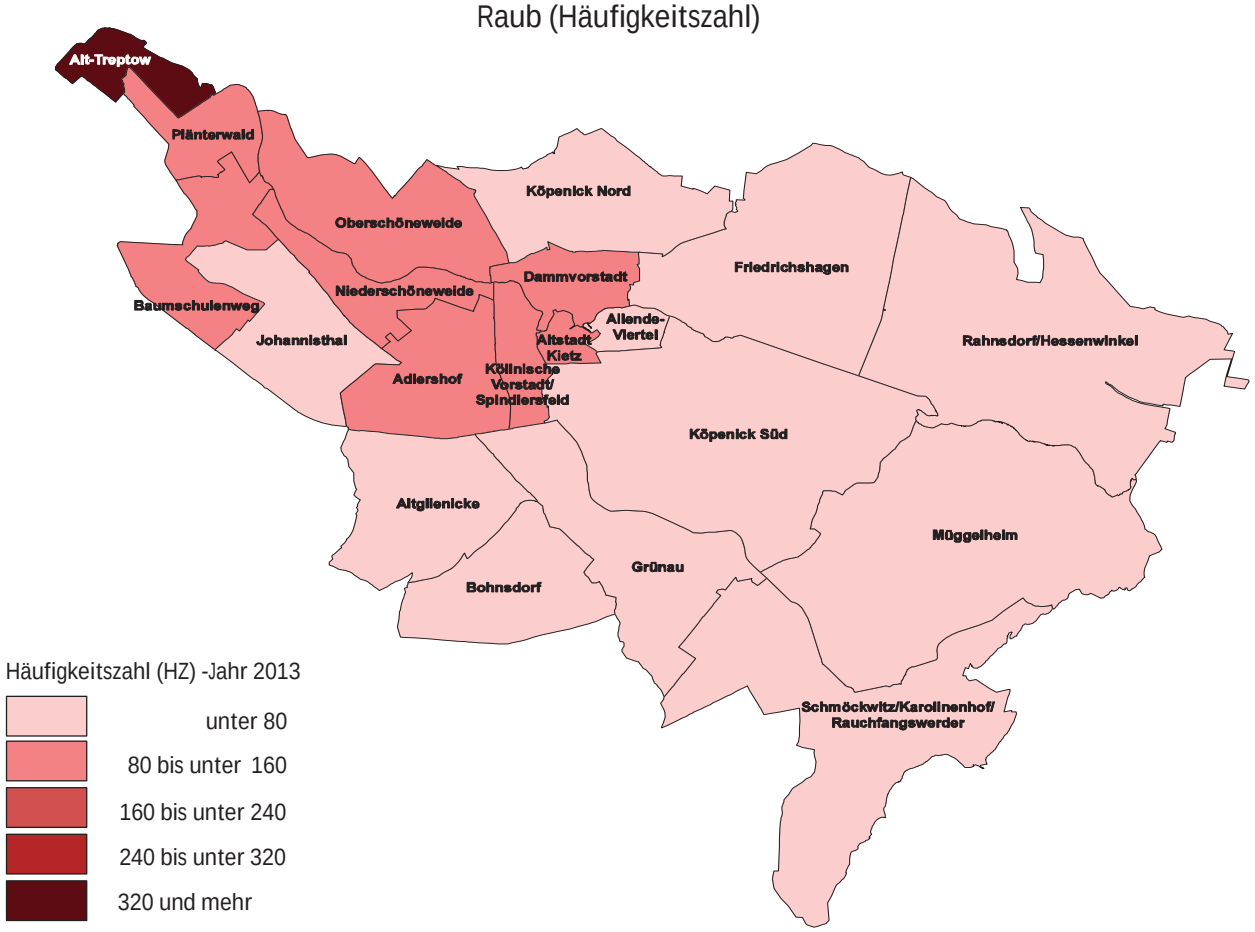

Raub (PKS-Schlüssel 210000)

Bezirksregion	Jahr 2012		Jahr 2013		Zu-/Abnahme			
	erfasste Fälle	HZ	erfasste Fälle	HZ	Fälle absolut	Fälle in %	HZ absolut	HZ in %
Alt-Treptow	45	412	45	406		x	- 6	(- 1,5)
Plänterwald	10	93	12	111	2	x	18	x
Baumschulenweg	20	116	21	120	1	x	4	(3,4)
Johannisthal	16	87	11	60	- 5	x	- 27	x
Oberschöneweide	16	83	23	117	7	x	34	x
Niederschöneweide	29	278	14	132	- 15	x	- 146	(- 52,5)
Adlershof	29	188	20	128	- 9	x	- 60	(- 31,9)
Kölln. Vorstadt/Spindlersf.	9	91	10	100	1	x	9	x
Altglienicke	11	43	7	27	- 4	x	- 16	x
Bohnsdorf	2	17	6	50	4	x	33	x
Grünau	3	56	2	36	- 1	x	- 20	x
Schmöckwitz/Karolinenhof		-	1	25	1	x	25	x
Köpenick Süd	2	13	1	6	- 1	x	- 7	x
Allende-Viertel	2	33		-	- 2	x	- 33	x
Altstadt Kietz	4	58	7	101	3	x	43	x
Müggelheim	1	15		-	- 1	x	- 15	x
Friedrichshagen	9	51	10	57	1	x	6	x
Rahnsdorf/Hessenwinkel	2	22	2	22		x		x
Dammvorstadt	7	74	10	105	3	x	31	x
Köpenick Nord	5	41	4	33	- 1	x	- 8	x
nicht zuzuordnen	3		3					

Bezirk Berlin Marzahn-Hellersdorf

Raub (Häufigkeitszahl)

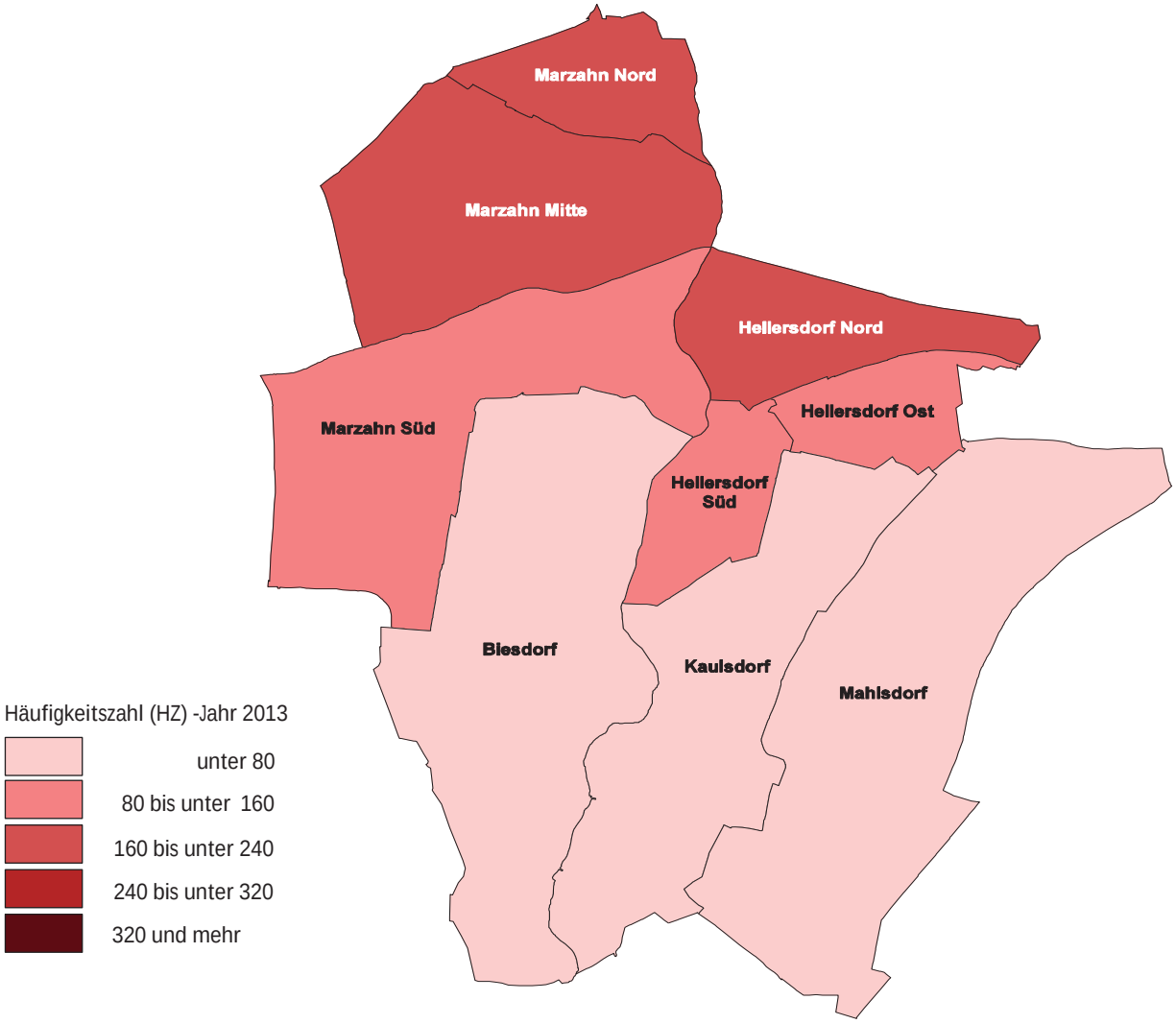

Raub (PKS-Schlüssel 210000)

Bezirksregion	Jahr 2012		Jahr 2013		Zu-/Abnahme			
	erfasste Fälle	HZ	erfasste Fälle	HZ	Fälle		HZ	
					absolut	in %	absolut	in %
Marzahn Nord	35	154	38	166	3	x	12	(7,8)
Marzahn Mitte	70	155	81	178	11	x	23	(14,8)
Marzahn Süd	55	152	52	142	- 3	x	- 10	(- 6,6)
Hellersdorf Nord	68	207	61	183	- 7	x	- 24	(- 11,6)
Hellersdorf Ost	26	141	30	159	4	x	18	(12,8)
Hellersdorf Süd	20	82	34	139	14	x	57	x
Biesdorf	20	80	10	39	- 10	x	- 41	x
Kaulsdorf	21	112	9	48	- 12	x	- 64	(- 57,1)
Mahlsdorf	6	22	9	33	3	x	11	x
nicht zuzuordnen	10		3					

Bezirk Berlin Lichtenberg

Raub (Häufigkeitszahl)

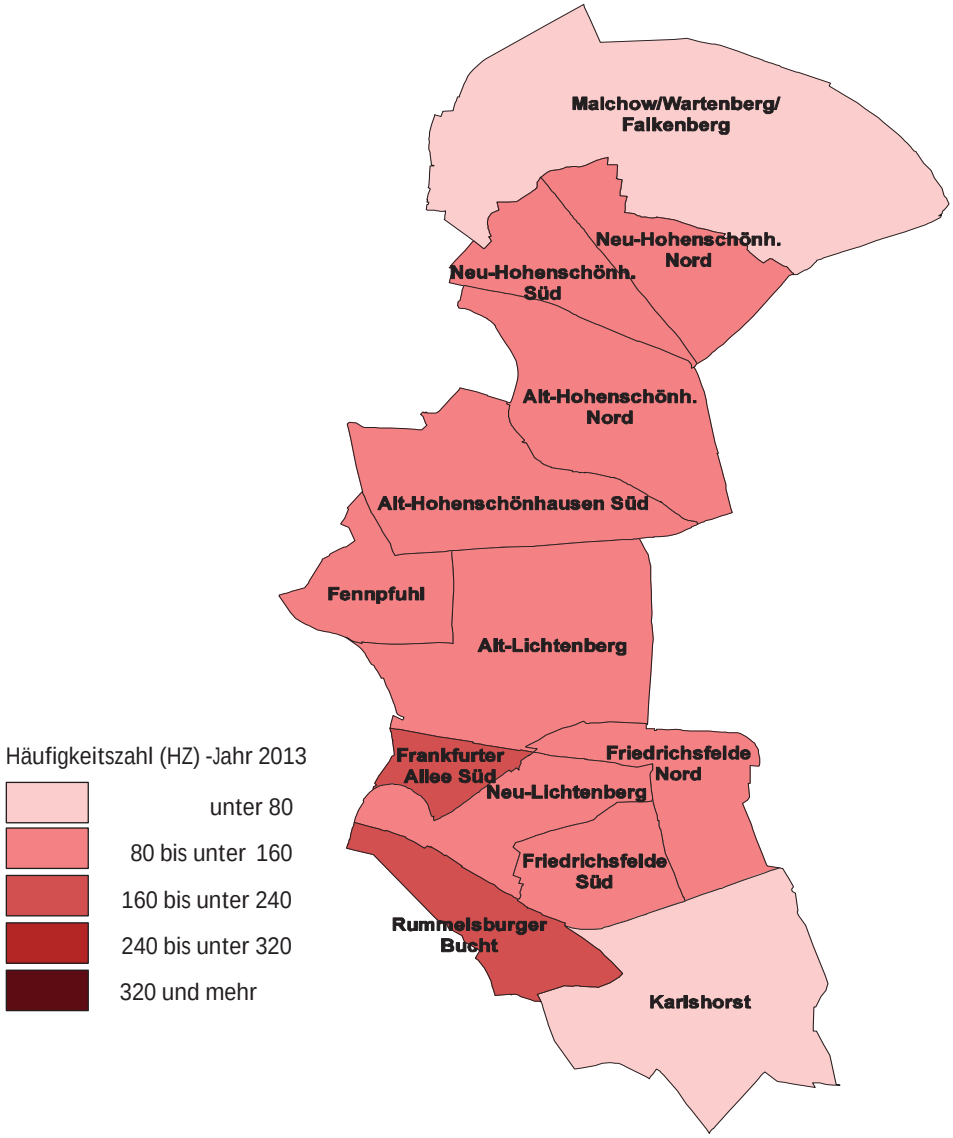

Raub (PKS-Schlüssel 210000)

Bezirksregion	Jahr 2012		Jahr 2013		Zu-/Abnahme			
	erfasste Fälle	HZ	erfasste Fälle	HZ	Fälle absolut	Fälle in %	HZ absolut	HZ in %
Malchow/Warten-/Falkenberg.....	2	48	2	47		x	- 1	x
Neu-Hohenschönhausen Nord.....	27	98	29	105	2	x	7	x
Neu-Hohenschönhausen Süd.....	30	116	32	124	2	x	8	(6,9)
Alt-Hohenschönhausen Nord.....	11	82	13	96	2	x	14	x
Alt-Hohenschönhausen Süd.....	26	88	31	105	5	x	17	x
Fennpfuhl.....	26	82	26	81		x	- 1	x
Alt-Lichtenberg.....	25	104	37	148	12	x	44	(42,3)
Frankfurter Allee Süd.....	19	197	18	180	- 1	x	- 17	(- 8,6)
Neu-Lichtenberg.....	27	92	34	113	7	x	21	x
Friedrichsfelde Nord.....	22	165	15	111	- 7	x	- 54	(- 32,7)
Friedrichsfelde Süd.....	28	116	25	102	- 3	x	- 14	(- 12,1)
Rummelsburger Bucht.....	4	123	6	181	2	x	58	(47,2)
Karlshorst.....	8	35	10	43	2	x	8	x
nicht zuzuordnen.....	5		4					

Bezirk Berlin Reinickendorf

Raub (Häufigkeitszahl)

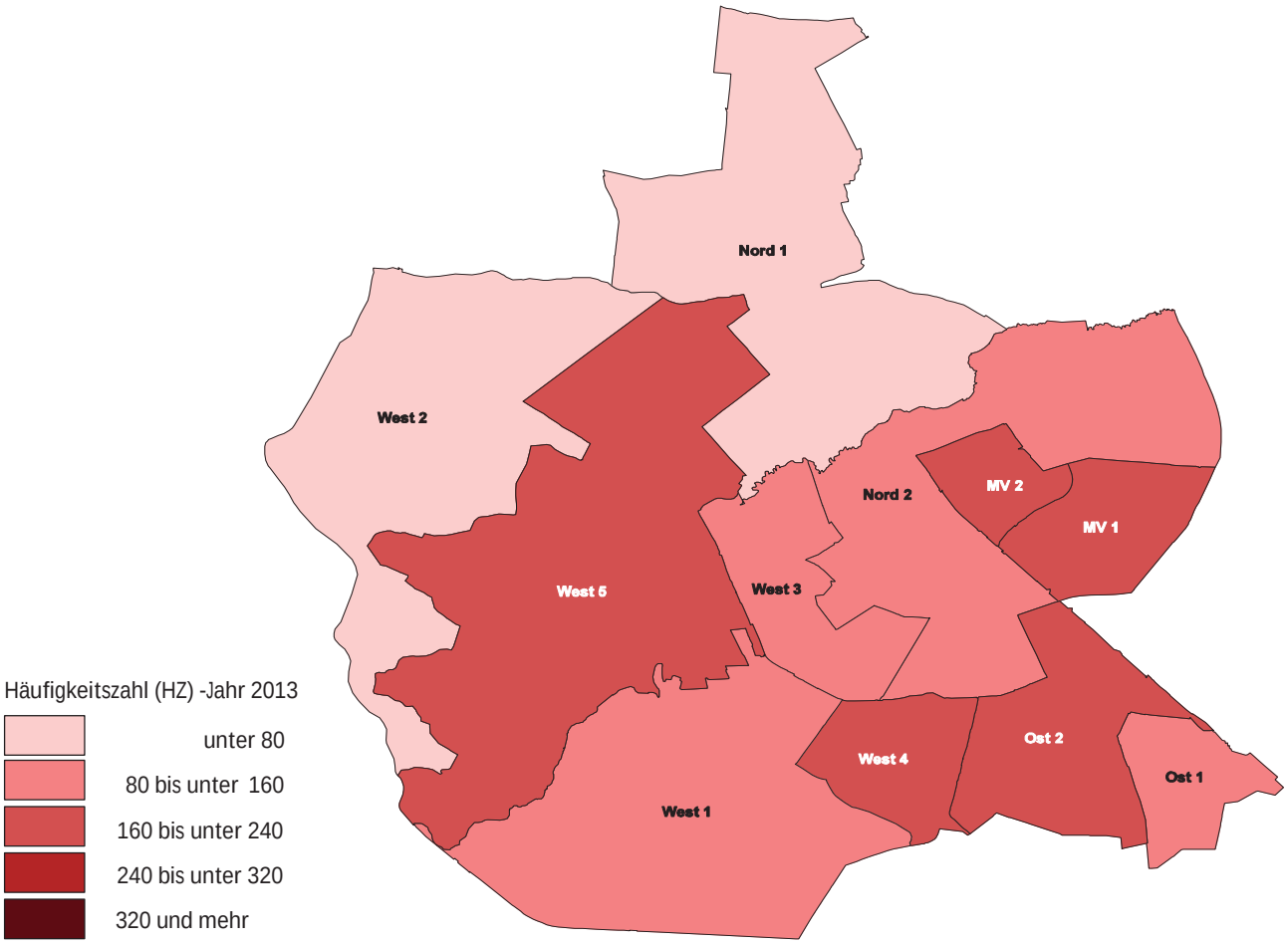

Raub (PKS-Schlüssel 210000)

Bezirksregion	Jahr 2012		Jahr 2013		Zu-/Abnahme			
	erfasste Fälle	HZ	erfasste Fälle	HZ	Fälle		HZ	
					absolut	in %	absolut	in %
Ost 1	60	234	38	146	- 22	x	- 88	(- 37,6)
Ost 2	50	196	49	190	- 1	x	- 6	(- 3,1)
West 1	11	76	15	104	4	x	28	x
West 4	49	196	45	177	- 4	x	- 19	(- 9,7)
West 5	24	235	23	223	- 1	x	- 12	(- 5,1)
West 2	8	34	4	17	- 4	x	- 17	x
Nord 1	20	61	25	76	5	x	15	x
Nord 2	38	130	45	151	7	x	21	(16,2)
MV 1	51	144	86	236	35	x	92	(63,9)
MV 2	9	110	14	165	5	x	55	(50,0)
West 3	15	94	15	94		x		x
nicht zuzuordnen	2		3					

Berlin - Straßenraub, Handtaschenraub (Häufigkeitszahl)

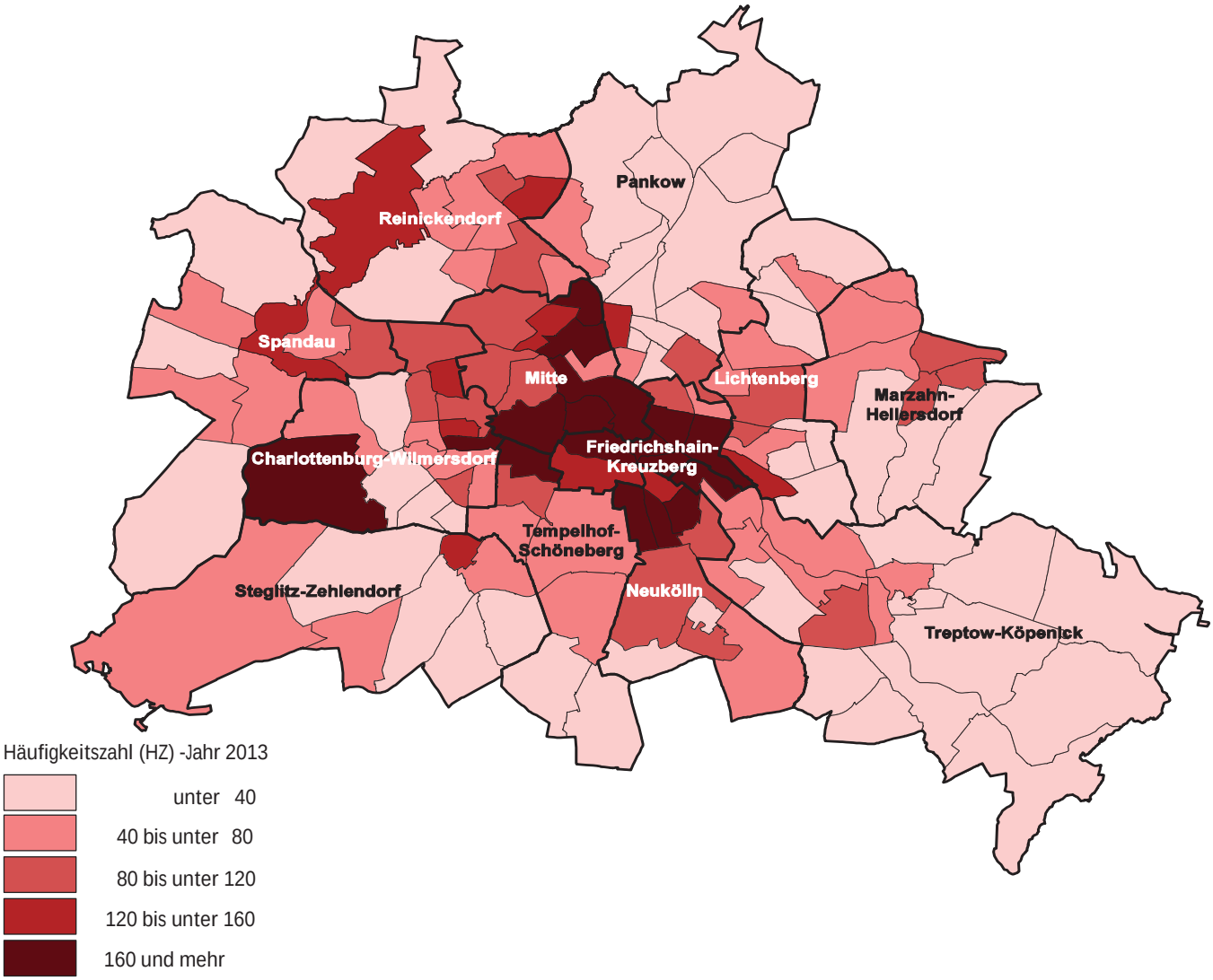

Straßenraub, Handtaschenraub (PKS-Schlüssel 216000, 217000)

Bezirk	Jahr 2012		Jahr 2013		Zu-/Abnahme			
	erfasste Fälle	HZ	erfasste Fälle	HZ	Fälle absolut	Fälle in %	HZ absolut	HZ in %
Mitte	610	182	573	167	- 37	- 6,1	- 15	- 8,2
Friedrichshain-Kreuzberg	504	189	622	229	118	23,4	40	21,2
Pankow	166	45	147	39	- 19	- 11,4	- 6	- 13,3
Charlottenburg-Wilmersdorf	248	78	258	80	10	4,0	2	2,6
Spandau	143	65	139	62	- 4	- 2,8	- 3	- 4,6
Steglitz-Zehlendorf	110	37	123	41	13	11,8	4	10,8
Tempelhof-Schöneberg	241	74	288	87	47	19,5	13	17,6
Neukölln	379	120	411	128	32	8,4	8	6,7
Treptow-Köpenick	94	39	109	45	15	16,0	6	15,4
Marzahn-Hellersdorf	148	59	158	62	10	6,8	3	5,1
Lichtenberg	112	43	129	49	17	15,2	6	14,0
Reinickendorf	131	53	178	71	47	35,9	18	34,0
Berlin, nicht zuzuordnen	46		56					
Berlin -Gesamt-	**2 932**	**87**	**3 191**	**94**	**259**	**8,8**	**7**	**7,8**

Bezirk Berlin Mitte

Straßenraub, Handtaschenraub (Häufigkeitszahl)

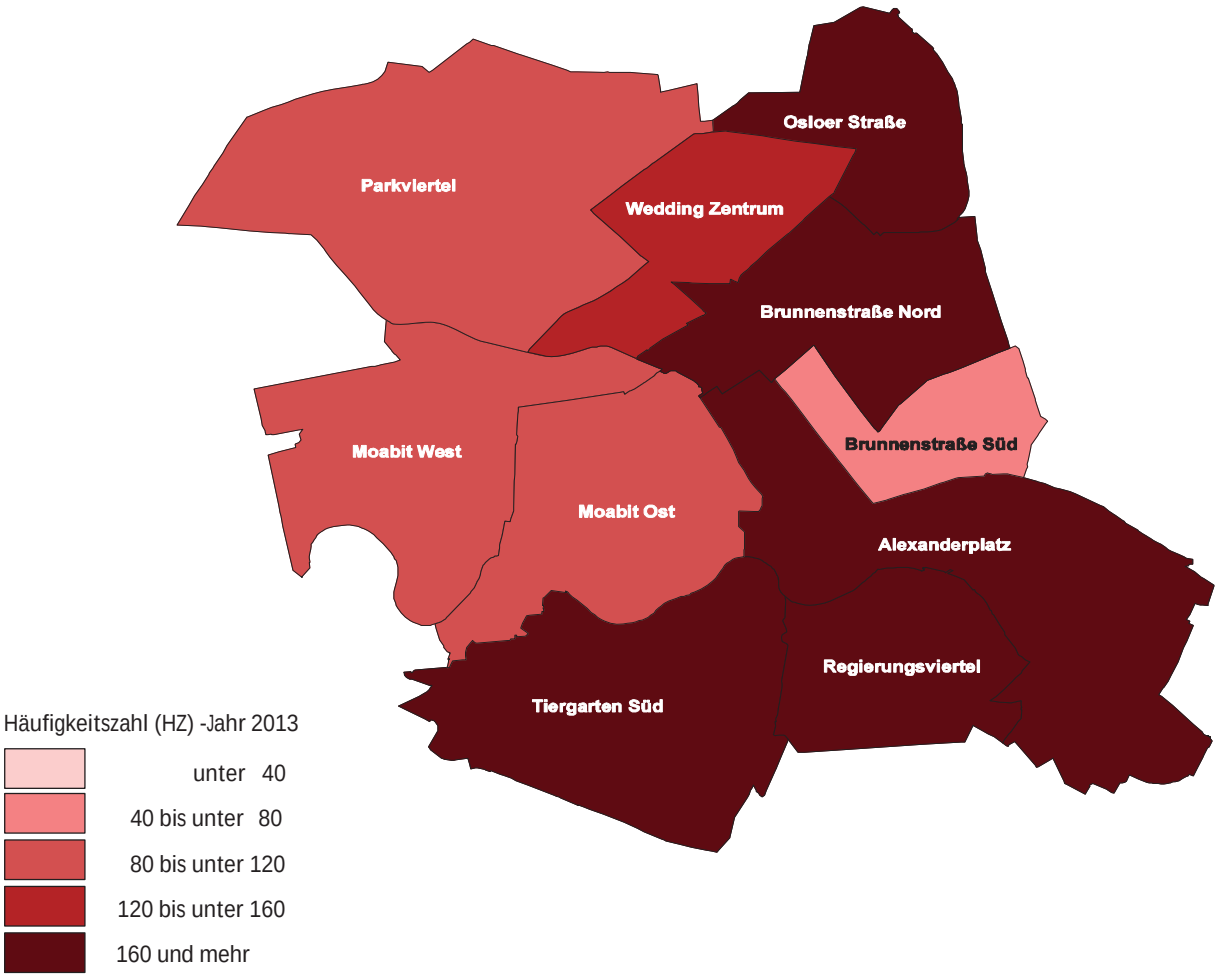

Straßenraub, Handtaschenraub (PKS-Schlüssel 216000, 217000)

Bezirksregion	Jahr 2012		Jahr 2013		Zu-/Abnahme			
	erfasste Fälle	HZ	erfasste Fälle	HZ	Fälle absolut	Fälle in %	HZ absolut	HZ in %
Tiergarten Süd	46	365	60	461	14	x	96	(26,3)
Regierungsviertel	29	316	25	269	- 4	x	- 47	(-14,9)
Alexanderplatz	136	288	149	310	13	9,6	22	7,6
Brunnenstraße Süd	25	98	14	53	- 11	x	- 45	x
Moabit West	51	122	47	110	- 4	x	- 12	(-9,8)
Moabit Ost	45	129	37	105	- 8	x	- 24	(-18,6)
Osloer Straße	46	131	64	177	18	x	46	(35,1)
Brunnenstraße Nord	71	201	58	162	- 13	x	- 39	(-19,4)
Parkviertel	48	116	38	90	- 10	x	- 26	(-22,4)
Wedding Zentrum	104	198	76	140	- 28	- 26,9	- 58	- 29,3
nicht zuzuordnen	9	-	5	-				

Bezirk Berlin Friedrichshain-Kreuzberg

Straßenraub, Handtaschenraub (Häufigkeitszahl)

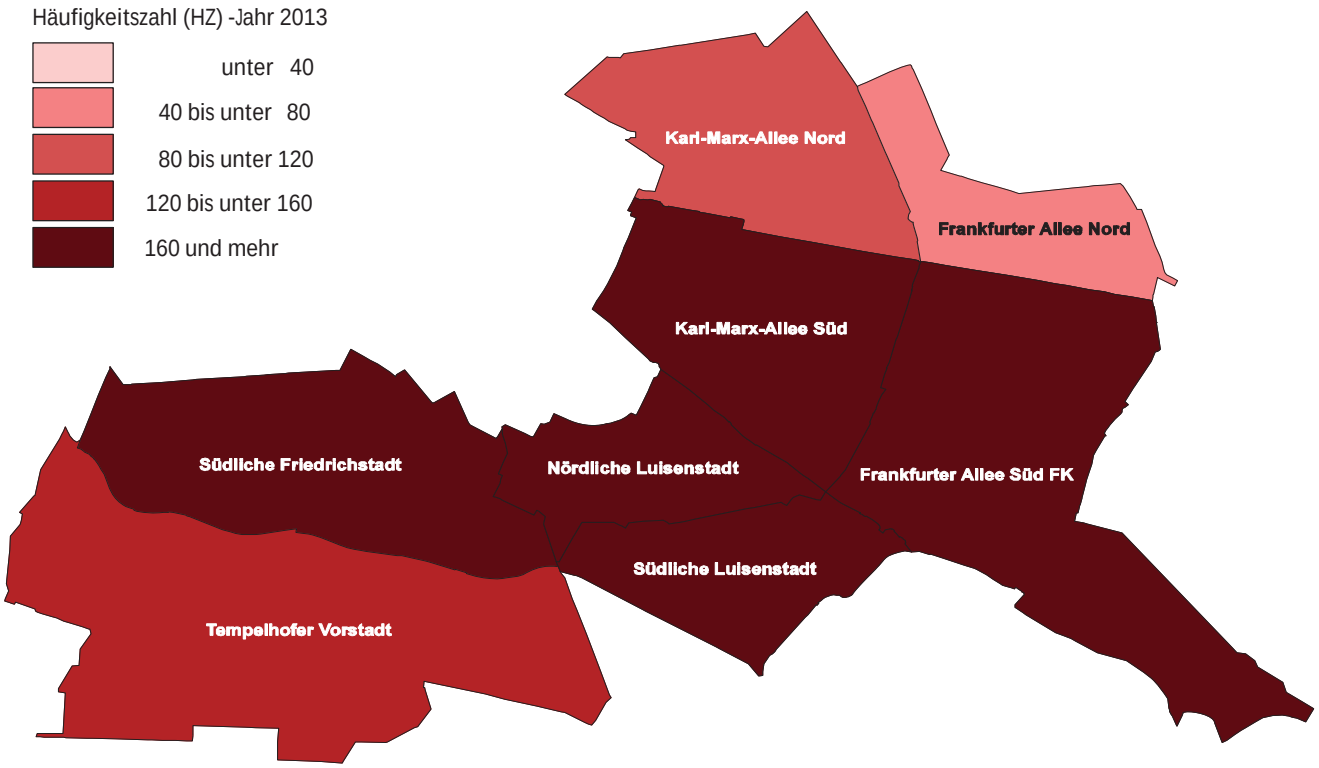

Straßenraub, Handtaschenraub (PKS-Schlüssel 216000, 217000)

Bezirksregion	Jahr 2012		Jahr 2013		Zu-/Abnahme			
	erfasste Fälle	HZ	erfasste Fälle	HZ	Fälle absolut	Fälle in %	HZ absolut	HZ in %
Südliche Friedrichstadt.....	71	182	76	192	5	x	10	(5,5)
Tempelhofer Vorstadt.....	88	144	81	131	- 7	x	- 13	(- 9,0)
Nördliche Luisenstadt.....	70	313	108	479	38	x	166	(53,0)
Südliche Luisenstadt.....	82	314	169	639	87	x	325	(103,5)
Karl-Marx-Allee Nord.....	34	153	18	80	- 16	x	- 73	(- 47,7)
Karl-Marx-Allee Süd.....	57	248	62	265	5	x	17	(6,9)
Frankfurter Allee Nord.....	16	59	19	69	3	x	10	x
Frankfurter Allee Süd FK.....	80	173	80	169		x	- 4	(- 2,3)
nicht zuzuordnen.....	6		9					

Bezirk Berlin Pankow

Straßenraub, Handtaschenraub (Häufigkeitszahl)

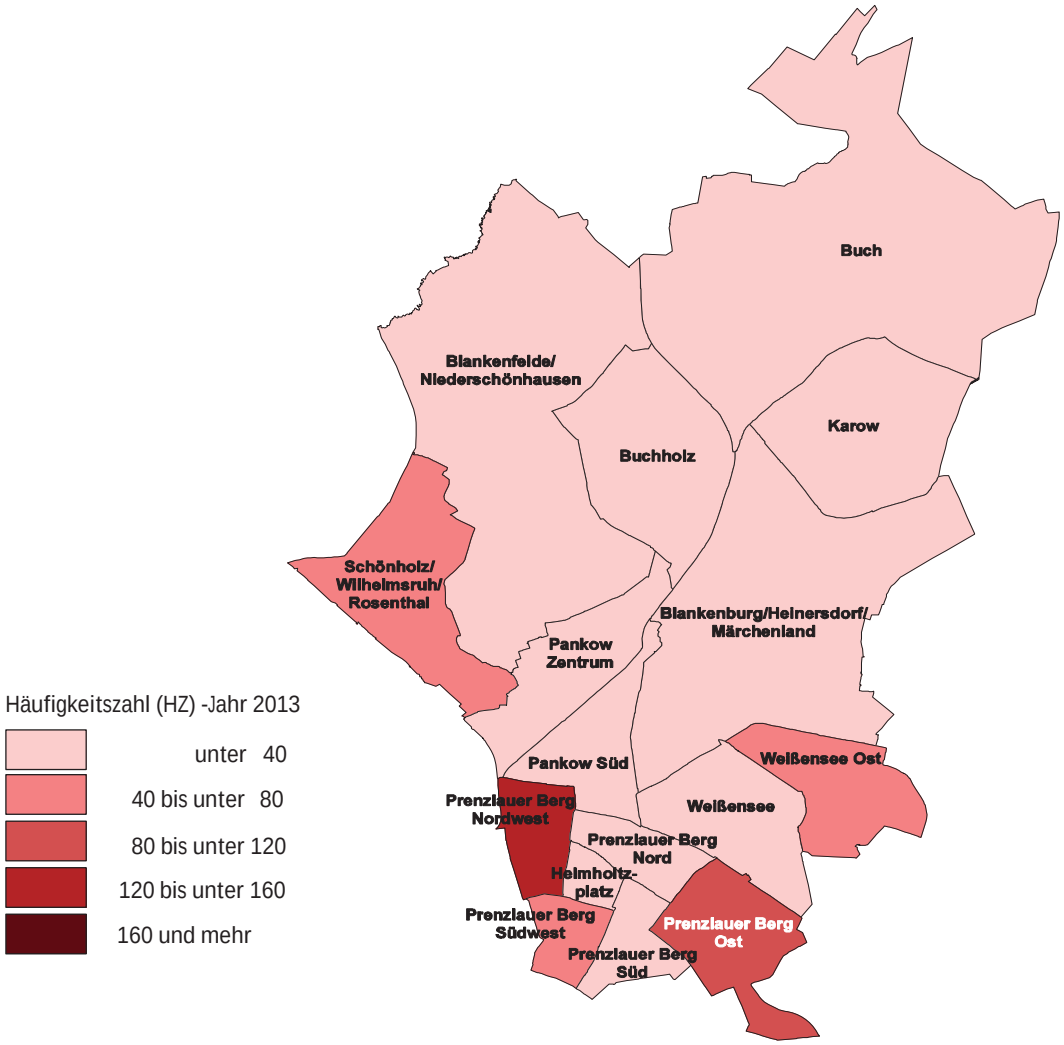

Straßenraub, Handtaschenraub (PKS-Schlüssel 216000, 217000)

Bezirksregion	Jahr 2012		Jahr 2013		Zu-/Abnahme			
	erfasste Fälle	HZ	erfasste Fälle	HZ	Fälle absolut	Fälle in %	HZ absolut	HZ in %
Buch	6	46	5	37	- 1	x	- 9	x
Blankenfelde/Niederschönhausen	4	16	4	15		x	- 1	x
Buchholz	3	18	2	12	- 1	x	- 6	x
Karow	1	5	2	11	1	x	6	x
Blankenburg/Heinersdorf	1	7	1	7		x		x
Pankow Süd	9	28	9	28		x		x
Schönholz/Wilhelmsruh/Rosenthal	10	58	8	47	- 2	x	- 11	x
Pankow Zentrum	11	34	11	33		x	- 1	x
Weißensee	15	46	9	27	- 6	x	- 19	x
Weißensee Ost	8	53	8	53		x		x
Prenzlauer Berg Nordwest	32	135	31	128	- 1	x	- 7	(- 5,2)
Prenzlauer Berg Nord	10	39	6	23	- 4	x	- 16	x
Helmholtzplatz	6	28	4	18	- 2	x	- 10	x
Prenzlauer Berg Ost	28	115	21	85	- 7	x	- 30	(- 26,1)
Prenzlauer Berg Südwest	12	50	12	48		x	- 2	x
Prenzlauer Berg Süd	6	19	9	29	3	x	10	x
nicht zuzuordnen	4		5					

Bezirk Berlin Charlottenburg-Wilmersdorf

Straßenraub, Handtaschenraub (Häufigkeitszahl)

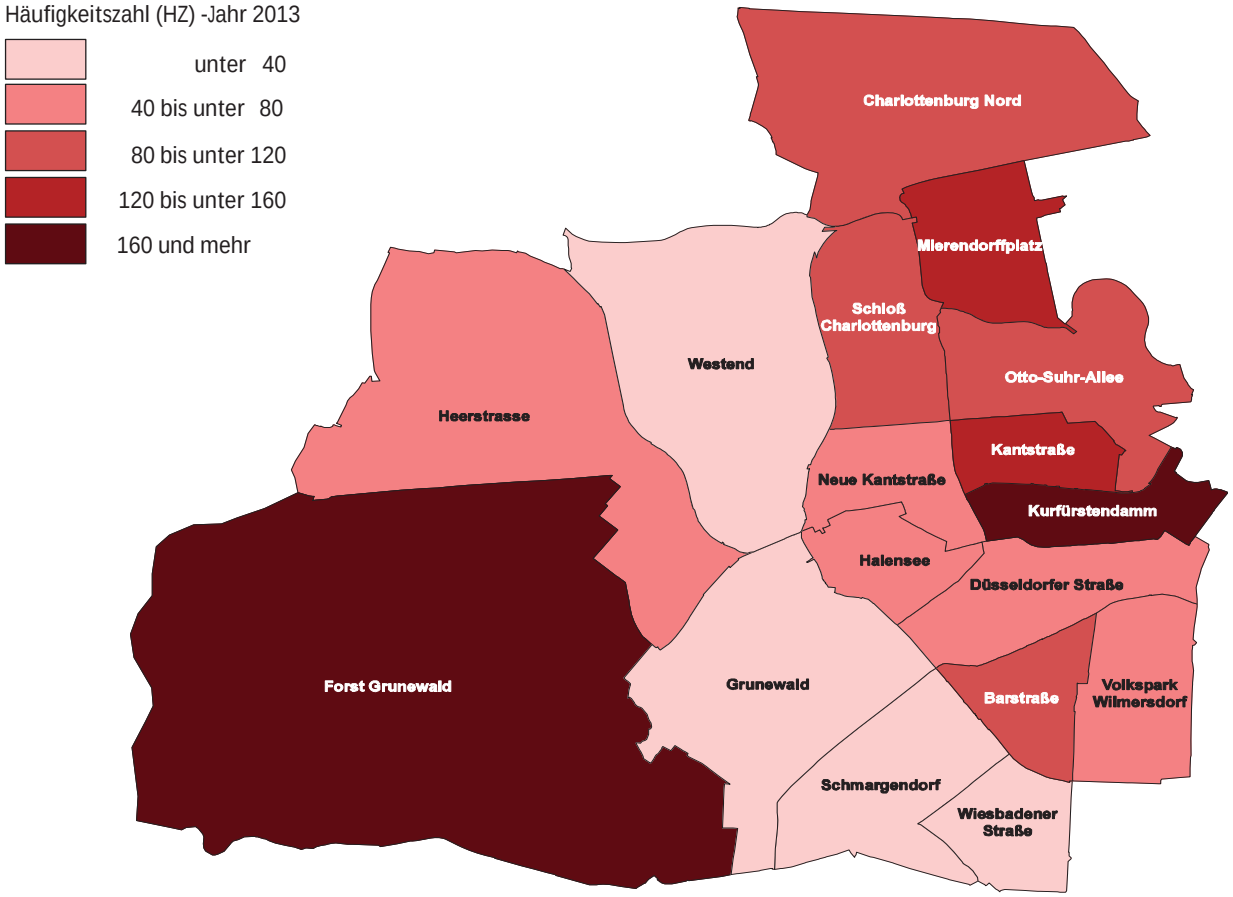

Straßenraub, Handtaschenraub (PKS-Schlüssel 216000, 217000)

Bezirksregion	Jahr 2012		Jahr 2013		Zu-/Abnahme			
	erfasste Fälle	HZ	erfasste Fälle	HZ	Fälle absolut	Fälle in %	HZ absolut	HZ in %
Charlottenburg Nord.....	14	77	16	87	2	x	10	x
Heerstraße.....	9	72	8	63	- 1	x	- 9	x
Westend.....	12	46	10	38	- 2	x	- 8	x
Schloß Charlottenburg.....	12	52	21	90	9	x	38	x
Mierendorffplatz.....	12	84	22	151	10	x	67	x
Otto-Suhr-Allee.....	15	59	24	93	9	x	34	x
Neue Kantstraße.....	23	100	17	73	- 6	x	- 27	(- 27,0)
Kantstraße.....	23	112	28	135	5	x	23	(20,5)
Kurfürstendamm.....	59	405	46	315	- 13	x	- 90	(- 22,2)
Halensee.....	8	56	8	55		x	- 1	x
Grunewald.....	5	28	6	33	1	x	5	x
Schmargendorf.....	1	7	5	36	4	x	29	x
Wiesbadener Straße.....	4	22	4	22		x		x
Düsseldorfer Straße.....	18	61	15	50	- 3	x	- 11	x
Barstraße.....	10	74	14	103	4	x	29	x
Volkspark Wilmersdorf.....	23	71	13	40	- 10	x	- 31	x
Forst Grunewald.....		-	1		1	x		
nicht zuzuordnen.....								

Bezirk Berlin Spandau

Straßenraub, Handtaschenraub (Häufigkeitszahl)

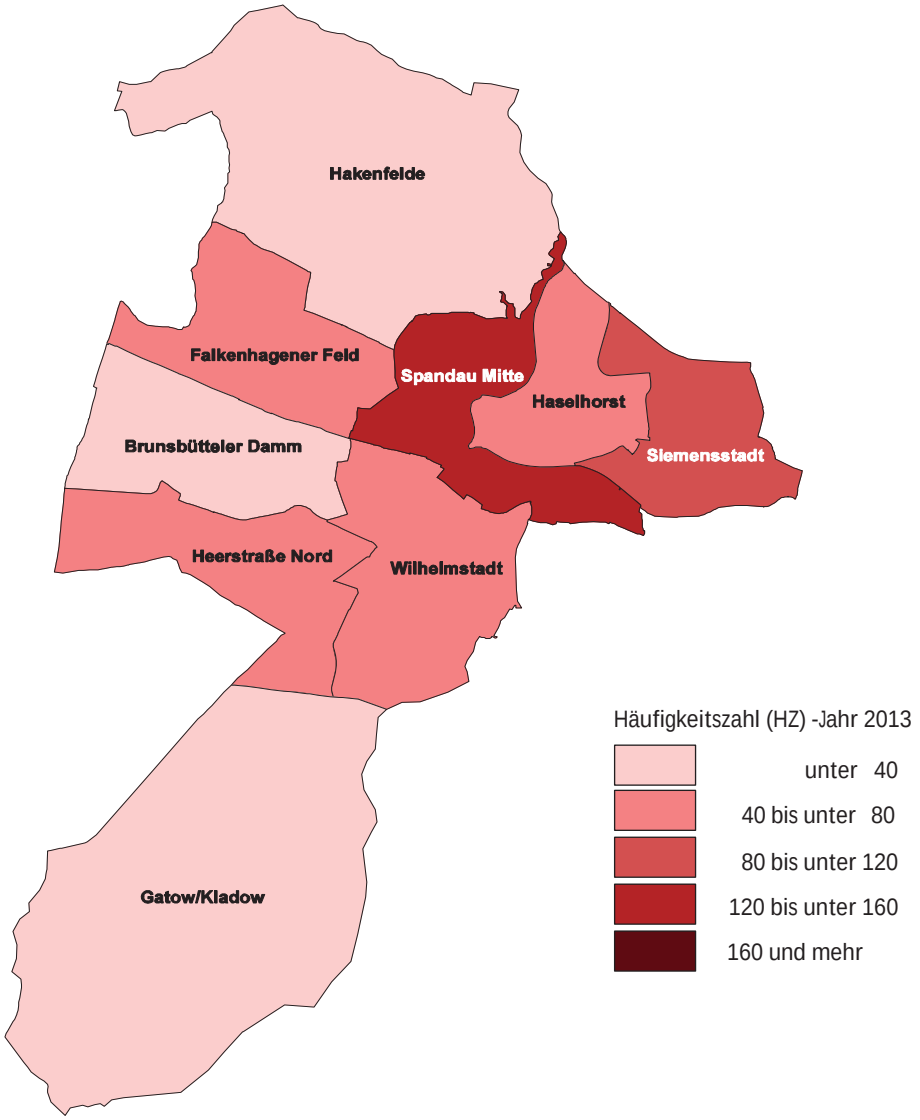

Straßenraub, Handtaschenraub (PKS-Schlüssel 216000, 217000)

Bezirksregion	Jahr 2012		Jahr 2013		Zu-/Abnahme			
	erfasste Fälle	HZ	erfasste Fälle	HZ	Fälle		HZ	
					absolut	in %	absolut	in %
Hakenfelde.....	3	13	8	35	5	x	22	x
Falkenhagener Feld.....	14	36	21	54	7	x	18	x
Spandau Mitte.....	52	158	46	136	- 6	x	- 22	(- 13,9)
Brunsbütteler Damm.....	5	22	7	30	2	x	8	x
Heerstraße Nord.....	20	75	15	56	- 5	x	- 19	x
Wilhelmstadt.....	25	74	21	61	- 4	x	- 13	x
Haselhorst.....	16	116	8	55	- 8	x	- 61	(- 52,6)
Siemensstadt.....	7	60	11	92	4	x	32	x
Gatow/Kladow.....	1	6	1	6		x		x
nicht zuzuordnen.....			1					

Bezirk Berlin Steglitz-Zehlendorf

Straßenraub, Handtaschenraub (Häufigkeitszahl)

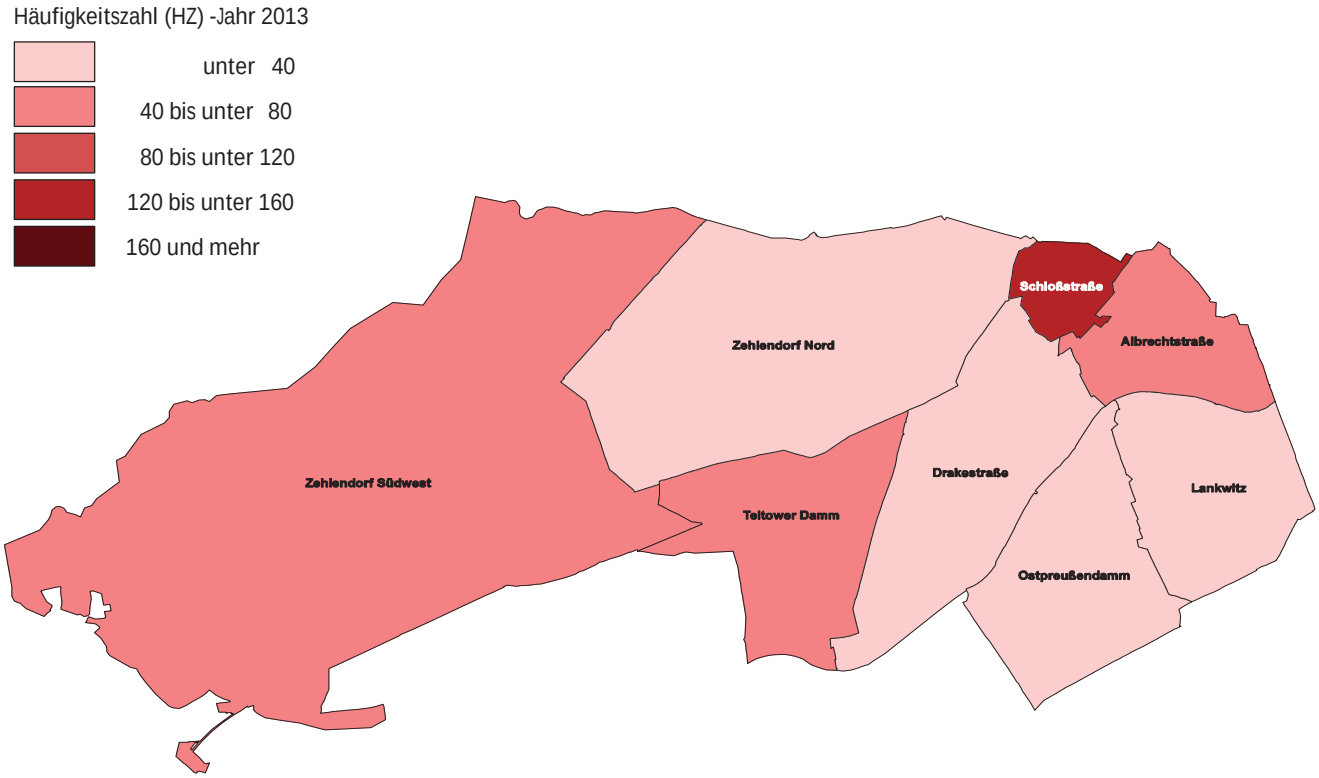

Straßenraub, Handtaschenraub (PKS-Schlüssel 216000, 217000)

Bezirksregion	Jahr 2012		Jahr 2013		Zu-/Abnahme			
	erfasste Fälle	HZ	erfasste Fälle	HZ	Fälle		HZ	
					absolut	in %	absolut	in %
Schloßstraße.....	28	131	32	148	4	x	17	(13,0)
Albrechtstraße.....	20	39	22	42	2	x	3	x
Lankwitz.....	15	36	14	34	- 1	x	- 2	x
Ostpreußendamm.....	7	20	11	31	4	x	11	x
Teltower Damm.....	7	21	14	43	7	x	22	x
Drakestraße.....	4	9	7	15	3	x	6	x
Zehlendorf Südwest.....	7	27	11	43	4	x	16	x
Zehlendorf Nord.....	22	53	11	26	- 11	x	- 27	x
nicht zuzuordnen.....			1					

Bezirk Berlin Tempelhof-Schöneberg

Straßenraub, Handtaschenraub (Häufigkeitszahl)

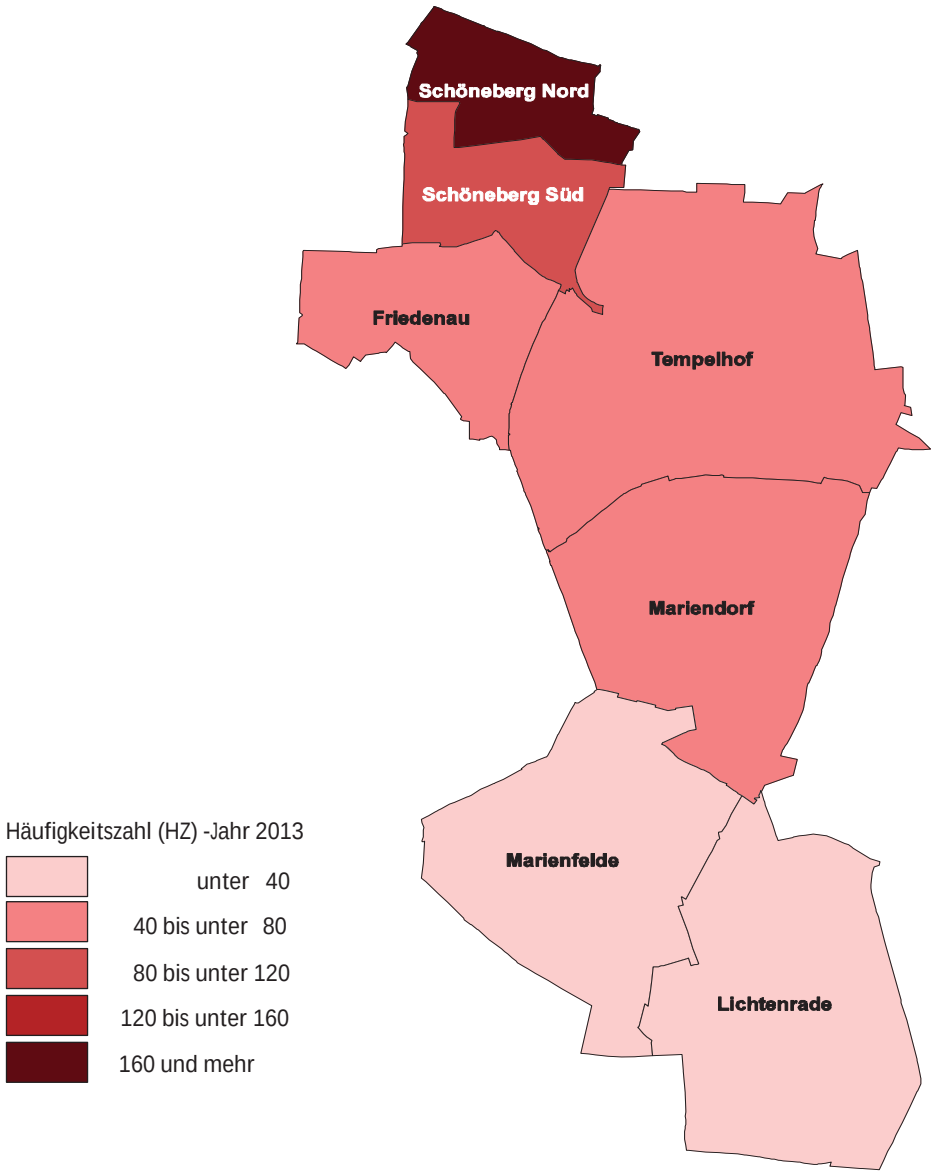

Straßenraub, Handtaschenraub (PKS-Schlüssel 216000, 217000)

Bezirksregion	Jahr 2012		Jahr 2013		Zu-/Abnahme			
	erfasste Fälle	HZ	erfasste Fälle	HZ	Fälle		HZ	
					absolut	in %	absolut	in %
Schöneberg Nord.....	98	208	122	260	24	x	52	(25,0)
Schöneberg Süd.....	35	74	49	103	14	x	29	x
Friedenau.....	15	34	19	43	4	x	9	x
Tempelhof.....	36	61	35	58	- 1	x	- 3	x
Mariendorf.....	20	40	35	70	15	x	30	x
Marienfelde.....	11	36	12	39	1	x	3	x
Lichtenrade.....	24	49	14	28	- 10	x	- 21	x
nicht zuzuordnen.....	2		2					

Bezirk Berlin Neukölln

Straßenraub, Handtaschenraub (Häufigkeitszahl)

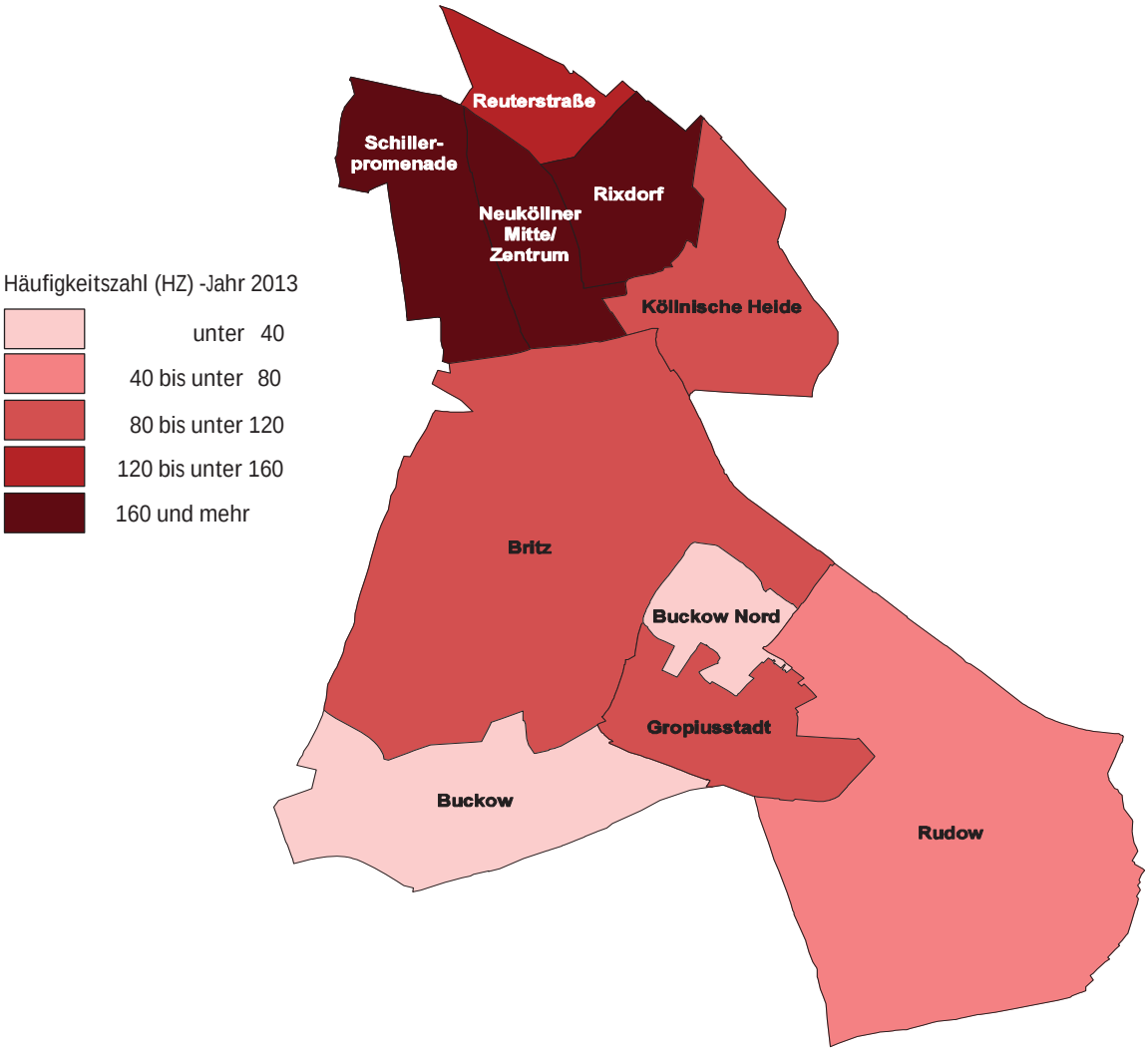

Straßenraub, Handtaschenraub (PKS-Schlüssel 216000, 217000)

Bezirksregion	Jahr 2012		Jahr 2013		Zu-/Abnahme			
	erfasste Fälle	HZ	erfasste Fälle	HZ	Fälle absolut	Fälle in %	HZ absolut	HZ in %
Schillerpromenade	84	272	84	266		x	- 6	(- 2,2)
Neuköllner Mitte/Zentrum	55	149	69	183	14	x	34	(22,8)
Reuterstraße	54	139	49	123	- 5	x	- 16	(- 11,5)
Rixdorf	55	142	72	182	17	x	40	(28,2)
Köllnische Heide	14	95	16	106	2	x	11	x
Britz	49	121	47	114	- 2	x	- 7	(- 5,8)
Buckow	7	25	11	39	4	x	14	x
Gropiusstadt	30	83	37	102	7	x	19	x
Buckow Nord	3	32	3	32		x		x
Rudow	25	60	19	45	- 6	x	- 15	x
nicht zuzuordnen	3		4					

Bezirk Berlin Treptow-Köpenick

Straßenraub, Handtaschenraub (Häufigkeitszahl)

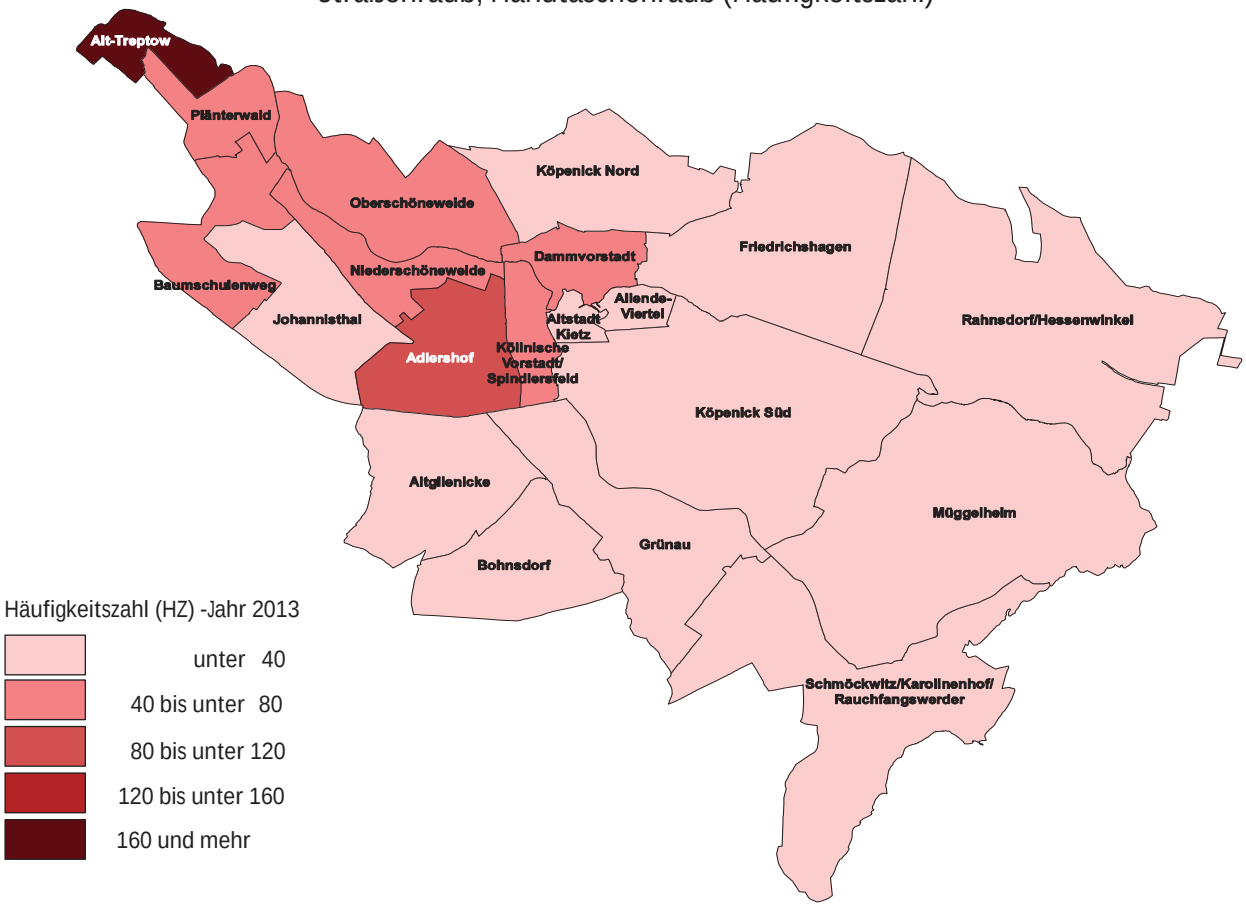

Straßenraub, Handtaschenraub (PKS-Schlüssel 216000, 217000)

Bezirksregion	Jahr 2012		Jahr 2013		Zu-/Abnahme			
	erfasste Fälle	HZ	erfasste Fälle	HZ	Fälle absolut	Fälle in %	HZ absolut	HZ in %
Alt-Treptow	24	220	29	261	5	x	41	(18,6)
Plänterwald	6	56	7	65	1	x	9	x
Baumschulenweg	10	58	12	69	2	x	11	x
Johannisthal	7	38	4	22	- 3	x	- 16	x
Oberschöneweide	5	26	13	66	8	x	40	x
Niederschöneweide	13	124	5	47	- 8	x	- 77	(- 62,1)
Adlershof	10	65	13	83	3	x	18	x
Kölln. Vorstadt/Spindlersf.	2	20	5	50	3	x	30	x
Altglienicke	6	23	3	12	- 3	x	- 11	x
Bohnsdorf		-	2	17	2	x	17	x
Grünau		-		-		x		x
Schmöckwitz/Karolinenhof		-		-		x		x
Köpenick Süd		-	1	6	1	x	6	x
Allende-Viertel		-		-		x		x
Altstadt Kietz		-	2	29	2	x	29	x
Müggelheim	1	15		-	- 1	x	- 15	x
Friedrichshagen	2	11	4	23	2	x	12	x
Rahnsdorf/Hessenwinkel	1	11	2	22	1	x	11	x
Dammvorstadt	4	42	4	42		x		x
Köpenick Nord	2	16	2	16		x		x
nicht zuzuordnen	1		1					

Bezirk Berlin Marzahn-Hellersdorf

Straßenraub, Handtaschenraub (Häufigkeitszahl)

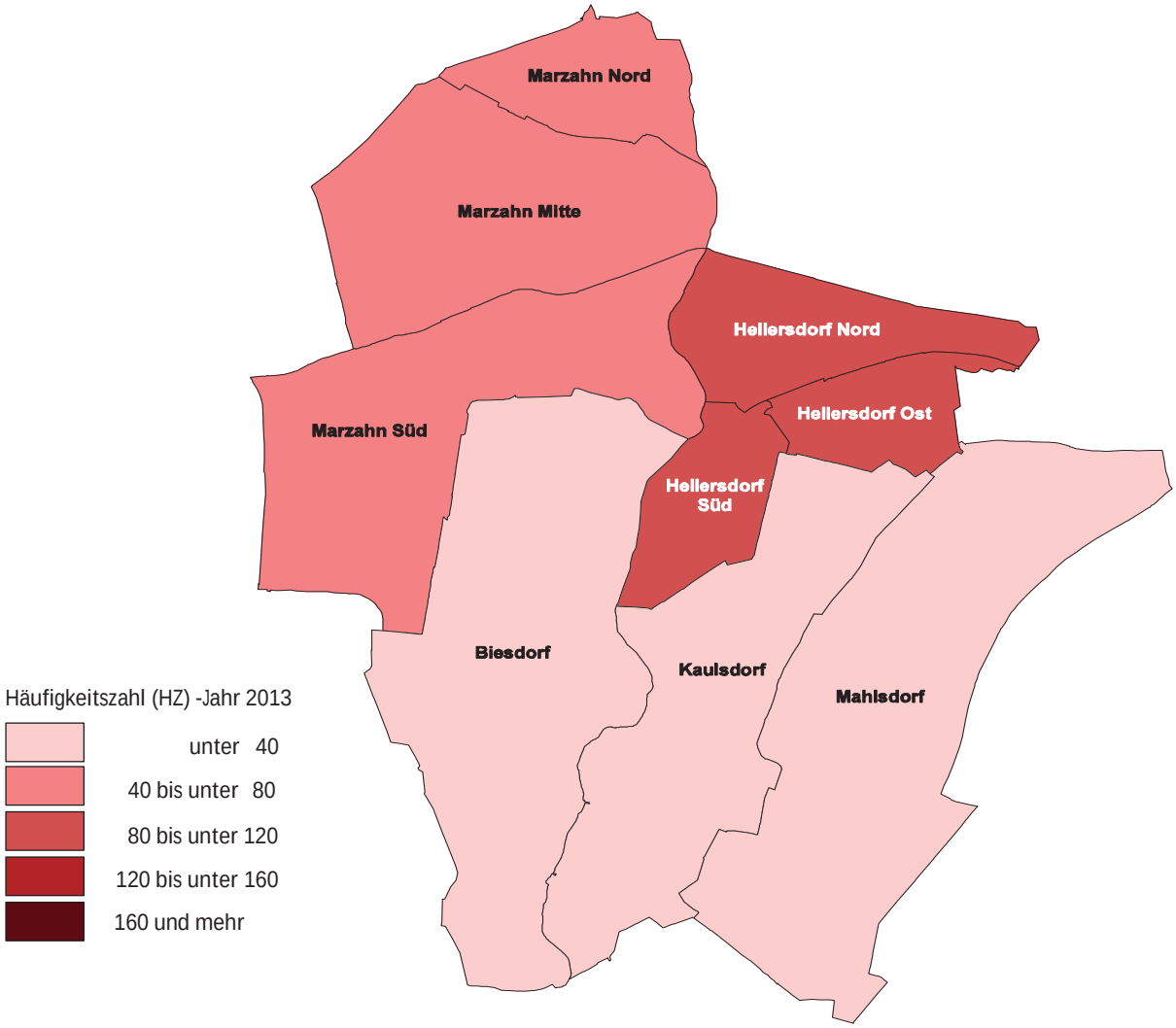

Straßenraub, Handtaschenraub (PKS-Schlüssel 216000, 217000)

Bezirksregion	Jahr 2012		Jahr 2013		Zu-/Abnahme			
	erfasste Fälle	HZ	erfasste Fälle	HZ	Fälle		HZ	
					absolut	in %	absolut	in %
Marzahn Nord	14	62	17	74	3	x	12	x
Marzahn Mitte	30	66	31	68	1	x	2	x
Marzahn Süd	20	55	21	57	1	x	2	x
Hellersdorf Nord	37	113	35	105	- 2	x	- 8	(- 7,1)
Hellersdorf Ost	11	60	20	106	9	x	46	x
Hellersdorf Süd	10	41	23	94	13	x	53	x
Biesdorf	10	40	4	16	- 6	x	- 24	x
Kaulsdorf	9	48	4	21	- 5	x	- 27	x
Mahlsdorf	4	15	3	11	- 1	x	- 4	x
nicht zuzuordnen	3							

Bezirk Berlin Lichtenberg

Straßenraub, Handtaschenraub (Häufigkeitszahl)

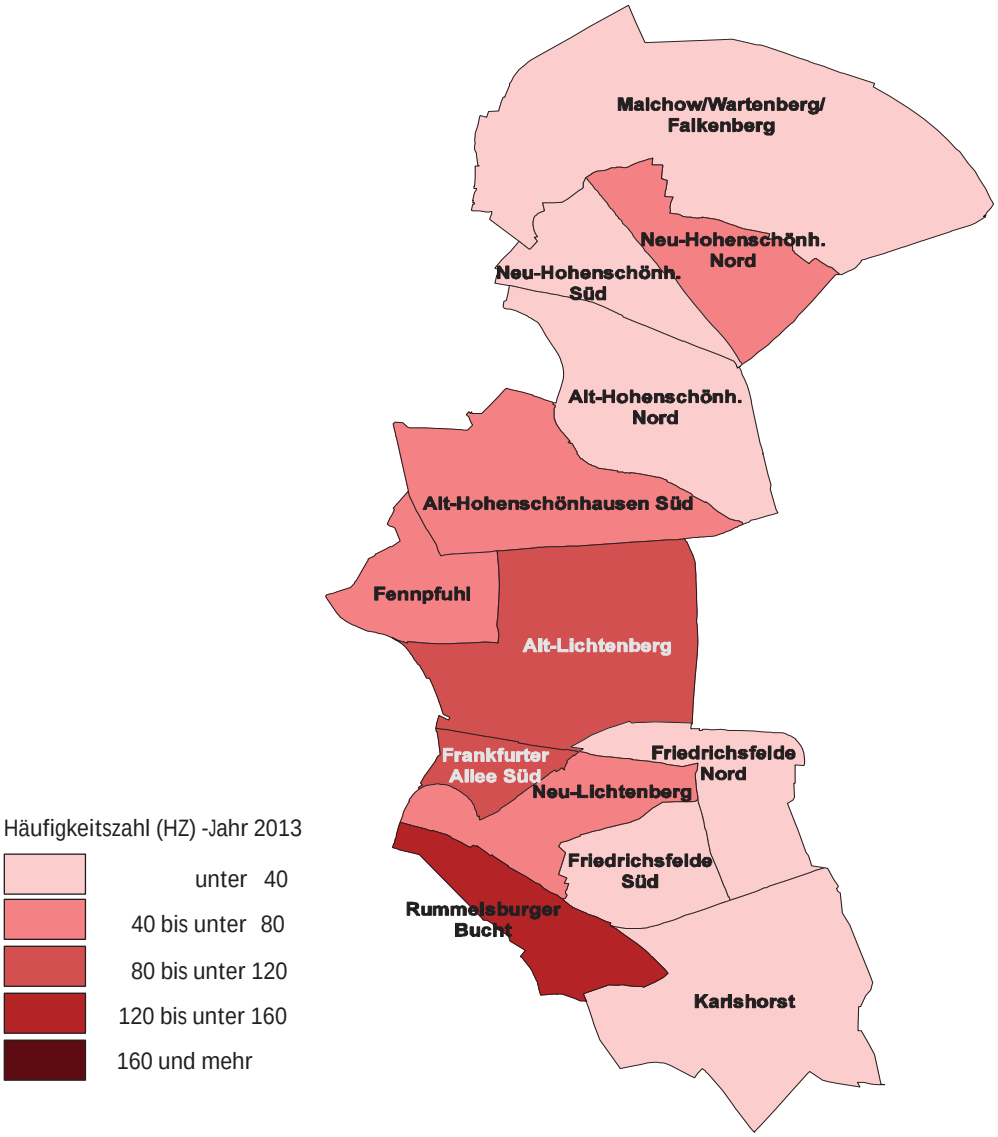

Straßenraub, Handtaschenraub (PKS-Schlüssel 216000, 217000)

Bezirksregion	Jahr 2012		Jahr 2013		Zu-/Abnahme			
	erfasste Fälle	HZ	erfasste Fälle	HZ	Fälle		HZ	
					absolut	in %	absolut	in %
Malchow/Warten-/Falkenberg.....	1	24		-	- 1	x	- 24	x
Neu-Hohenschönhausen Nord.....	11	40	16	58	5	x	18	x
Neu-Hohenschönhausen Süd.....	12	46	8	31	- 4	x	- 15	x
Alt-Hohenschönhausen Nord.....	4	30	3	22	- 1	x	- 8	x
Alt-Hohenschönhausen Süd.....	10	34	16	54	6	x	20	x
Fennpfuhl.....	14	44	14	44		x		x
Alt-Lichtenberg.....	10	42	22	88	12	x	46	x
Frankfurter Allee Süd.....	6	62	10	100	4	x	38	x
Neu-Lichtenberg.....	16	54	16	53		x	- 1	x
Friedrichsfelde Nord.....	15	113	4	30	- 11	x	- 83	(- 73,5)
Friedrichsfelde Süd.....	9	37	8	33	- 1	x	- 4	x
Rummelsburger Bucht.....		-	4	121	4	x	121	x
Karlshorst.....	3	13	5	21	2	x	8	x
nicht zuzuordnen.....	1		3					

Bezirk Berlin Reinickendorf

Straßenraub, Handtaschenraub (Häufigkeitszahl)

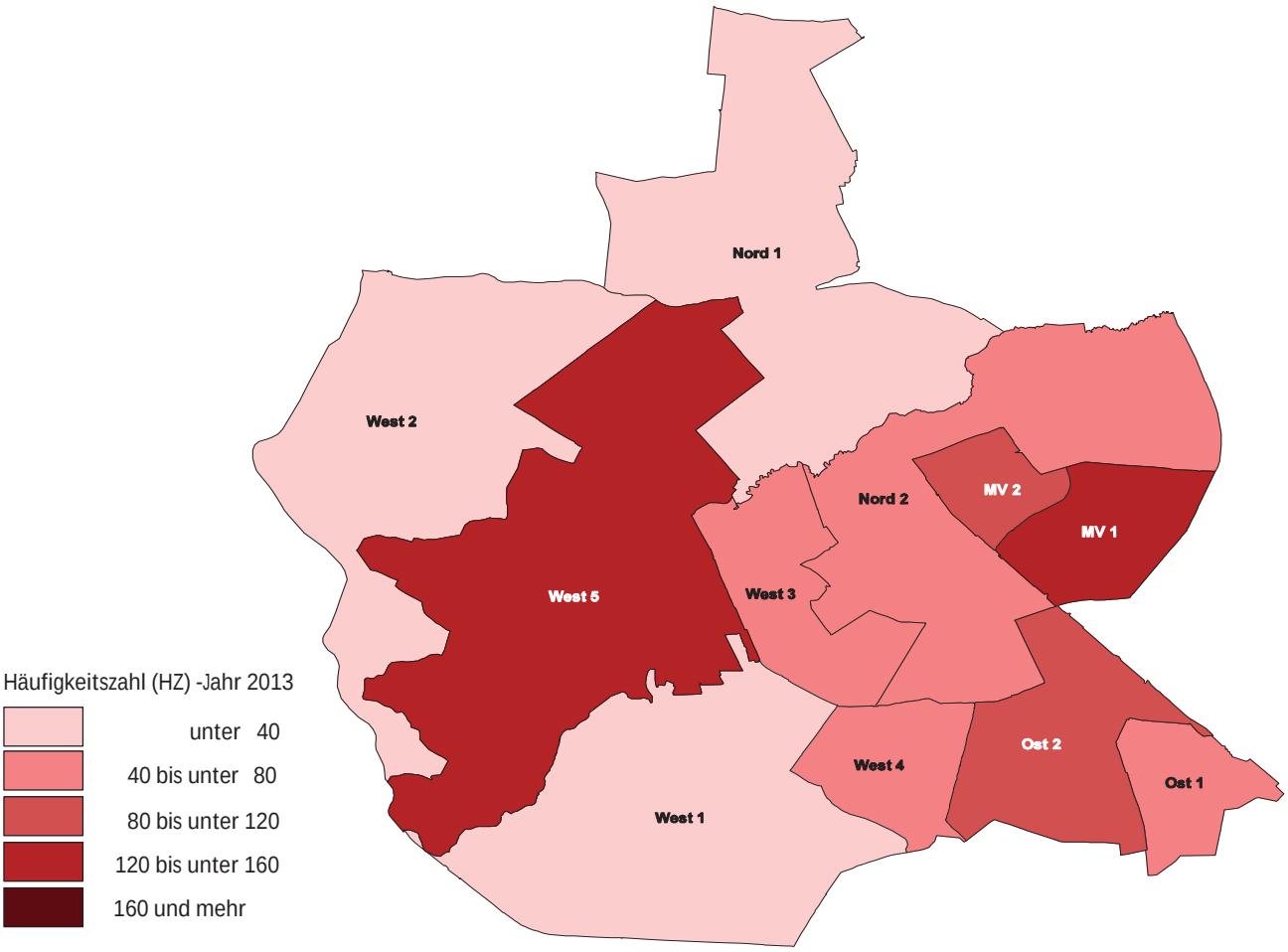

Straßenraub, Handtaschenraub (PKS-Schlüssel 216000, 217000)

Bezirksregion	Jahr 2012		Jahr 2013		Zu-/Abnahme			
	erfasste Fälle	HZ	erfasste Fälle	HZ	Fälle		HZ	
					absolut	in %	absolut	in %
Ost 1	21	82	15	58	- 6	x	- 24	x
Ost 2	18	71	21	81	3	x	10	x
West 1	3	21	5	35	2	x	14	x
West 4	19	76	17	67	- 2	x	- 9	x
West 5	14	137	13	126	- 1	x	- 11	(- 8,0)
West 2	3	13	3	13		x		x
Nord 1	8	24	9	27	1	x	3	x
Nord 2	12	41	22	74	10	x	33	x
MV 1	21	59	57	157	36	x	98	x
MV 2	2	24	9	106	7	x	82	x
West 3	9	56	7	44	- 2	x	- 12	x
nicht zuzuordnen	1							

Berlin - Körperverletzung -insgesamt- (Häufigkeitszahl)

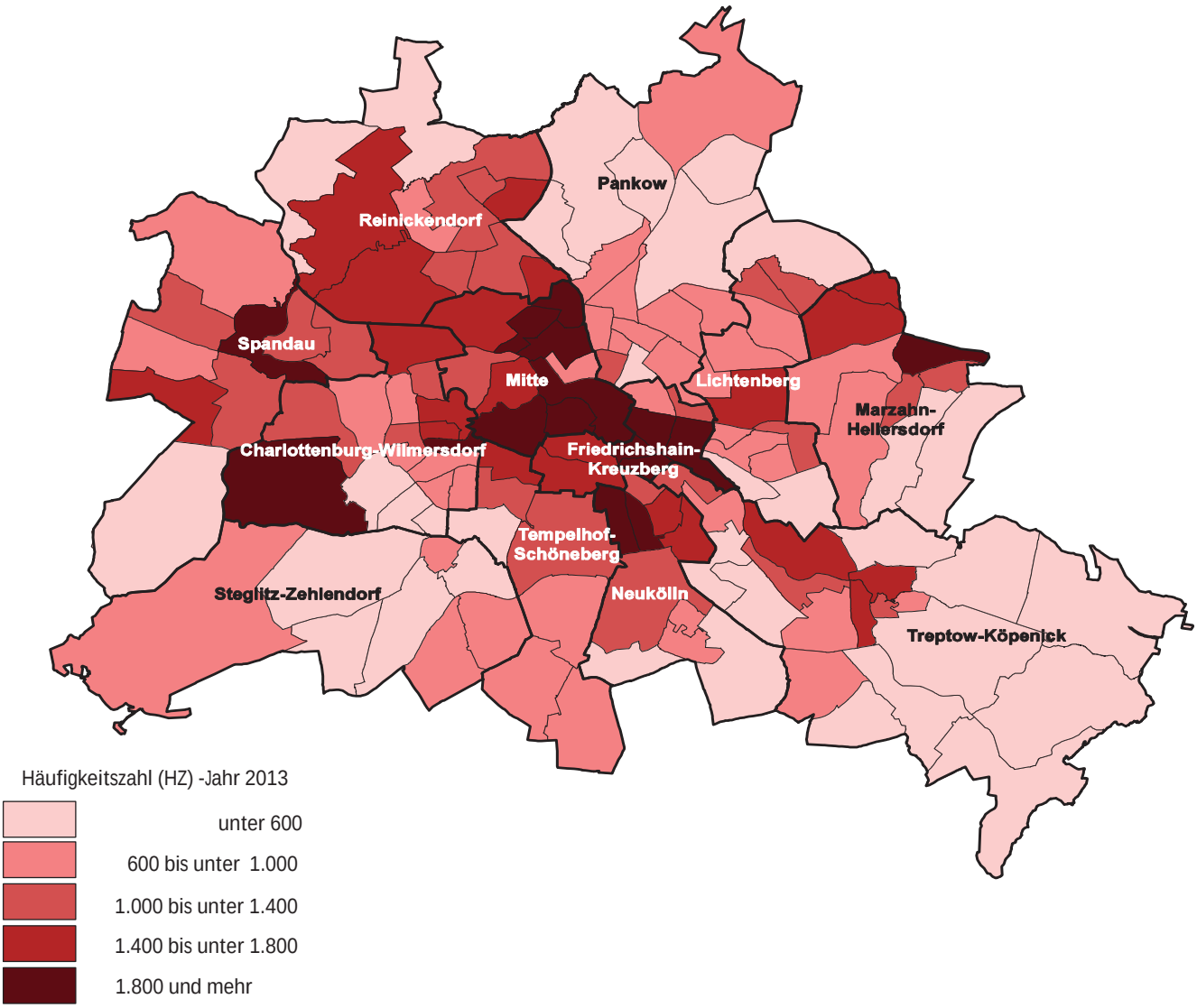

Körperverletzung -insgesamt- (PKS-Schlüssel 220000)

Bezirk	Jahr 2012		Jahr 2013		Zu-/Abnahme			
	erfasste Fälle	HZ	erfasste Fälle	HZ	Fälle absolut	Fälle in %	HZ absolut	HZ in %
Mitte	7 921	2 360	7 515	2 187	- 406	- 5,1	- 173	- 7,3
Friedrichshain-Kreuzberg	4 613	1 729	4 792	1 767	179	3,9	38	2,2
Pankow	2 790	760	2 793	747	3	0,1	- 13	- 1,7
Charlottenburg-Wilmersdorf	4 224	1 333	3 998	1 246	- 226	- 5,4	- 87	- 6,5
Spandau	2 848	1 286	2 817	1 255	- 31	- 1,1	- 31	- 2,4
Steglitz-Zehlendorf	1 752	596	1 786	602	34	1,9	6	1,0
Tempelhof-Schöneberg	3 216	983	3 320	1 008	104	3,2	25	2,5
Neukölln	4 368	1 384	4 079	1 273	- 289	- 6,6	- 111	- 8,0
Treptow-Köpenick	1 923	794	2 009	821	86	4,5	27	3,4
Marzahn-Hellersdorf	3 052	1 219	3 139	1 241	87	2,9	22	1,8
Lichtenberg	2 570	994	2 433	927	- 137	- 5,3	- 67	- 6,7
Reinickendorf	2 876	1 169	2 780	1 115	- 96	- 3,3	- 54	- 4,6
Berlin, nicht zuzuordnen	330		334					
Berlin -Gesamt-	**42 483**	**1 260**	**41 795**	**1 228**	**- 688**	**-1,6**	**- 32**	**-2,6**

Bezirk Berlin Mitte

Körperverletzung -insgesamt (Häufigkeitszahl)

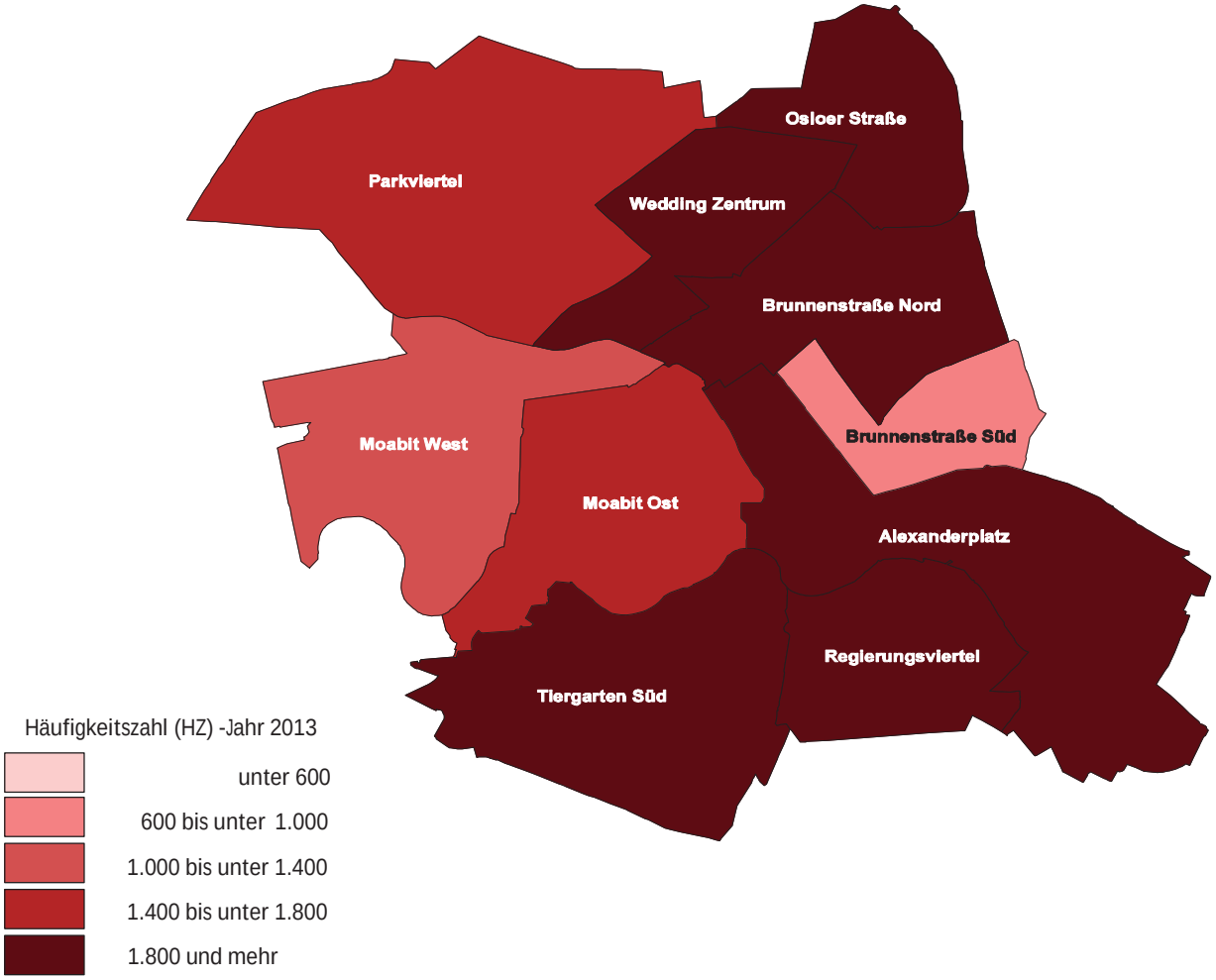

Körperverletzung -insgesamt (PKS-Schlüssel 220000)

Bezirksregion	Jahr 2012		Jahr 2013		Zu-/Abnahme			
	erfasste Fälle	HZ	erfasste Fälle	HZ	Fälle absolut	Fälle in %	HZ absolut	HZ in %
Tiergarten Süd.....	586	4 651	522	4 012	- 64	- 10,9	- 639	- 13,7
Regierungsviertel.....	474	5 171	480	5 162	6	1,3	- 9	- 0,2
Alexanderplatz.....	1 541	3 265	1 442	2 996	- 99	- 6,4	- 269	- 8,2
Brunnenstraße Süd.....	254	993	226	851	- 28	- 11,0	- 142	- 14,3
Moabit West.....	629	1 502	597	1 396	- 32	- 5,1	- 106	- 7,1
Moabit Ost.....	549	1 576	496	1 405	- 53	- 9,7	- 171	- 10,9
Osloer Straße.....	785	2 240	814	2 249	29	3,7	9	0,4
Brunnenstraße Nord.....	675	1 913	667	1 861	- 8	- 1,2	- 52	- 2,7
Parkviertel.....	783	1 889	712	1 681	- 71	- 9,1	- 208	- 11,0
Wedding Zentrum.....	1 210	2 303	1 156	2 136	- 54	- 4,5	- 167	- 7,3
nicht zuzuordnen.....	435	-	403	-				

Bezirk Berlin Friedrichshain-Kreuzberg

Körperverletzung -insgesamt (Häufigkeitszahl)

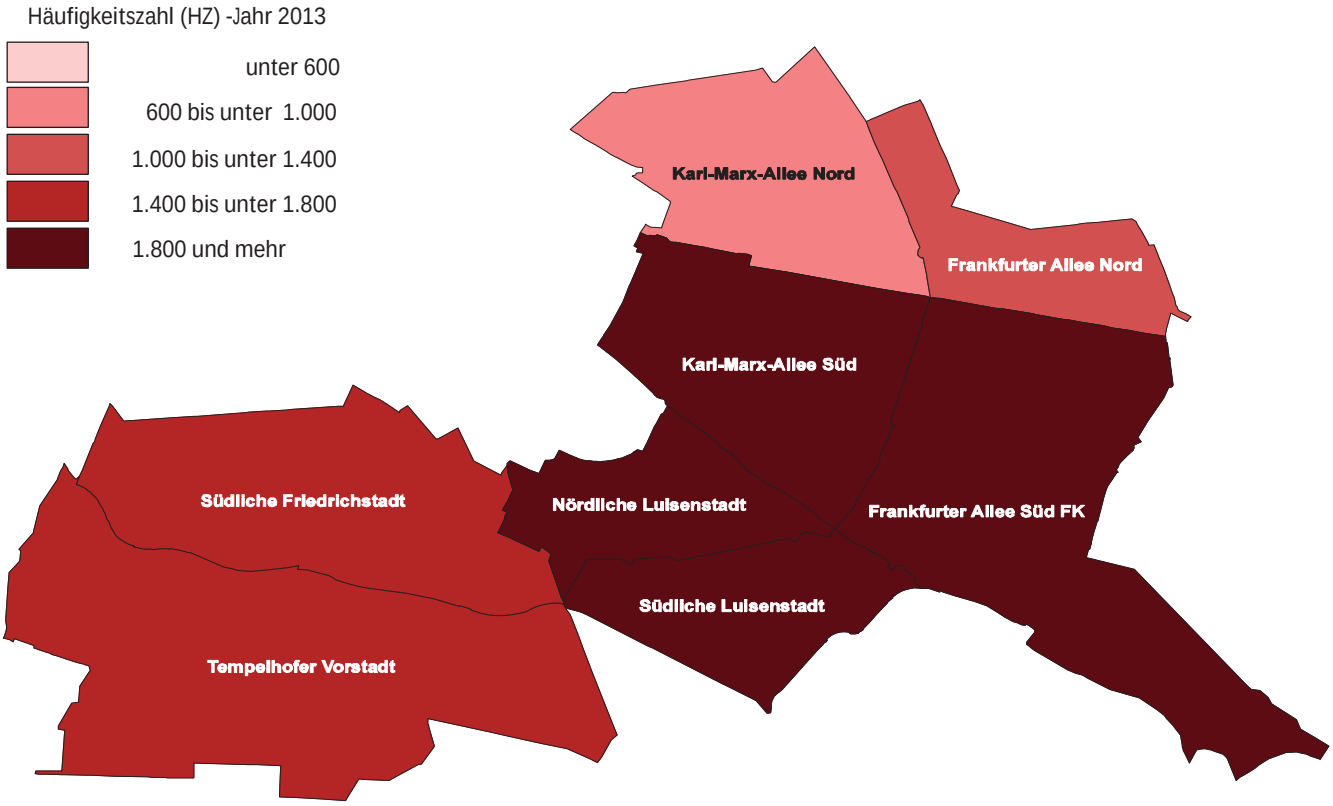

Körperverletzung -insgesamt (PKS-Schlüssel 220000)

Bezirksregion	Jahr 2012		Jahr 2013		Zu-/Abnahme			
	erfasste Fälle	HZ	erfasste Fälle	HZ	Fälle absolut	Fälle in %	HZ absolut	HZ in %
Südliche Friedrichstadt.....	723	1 856	693	1 754	- 30	- 4,1	- 102	- 5,5
Tempelhofer Vorstadt.....	932	1 530	869	1 403	- 63	- 6,8	- 127	- 8,3
Nördliche Luisenstadt.....	504	2 256	556	2 466	52	10,3	210	9,3
Südliche Luisenstadt.....	395	1 513	562	2 126	167	42,3	613	40,5
Karl-Marx-Allee Nord.....	235	1 056	214	952	- 21	- 8,9	- 104	- 9,8
Karl-Marx-Allee Süd.....	471	2 053	492	2 101	21	4,5	48	2,3
Frankfurter Allee Nord.....	265	976	298	1 080	33	12,5	104	10,7
Frankfurter Allee Süd FK.....	865	1 872	897	1 898	32	3,7	26	1,4
nicht zuzuordnen.....	223		211					

Bezirk Berlin Pankow

Körperverletzung -insgesamt (Häufigkeitszahl)

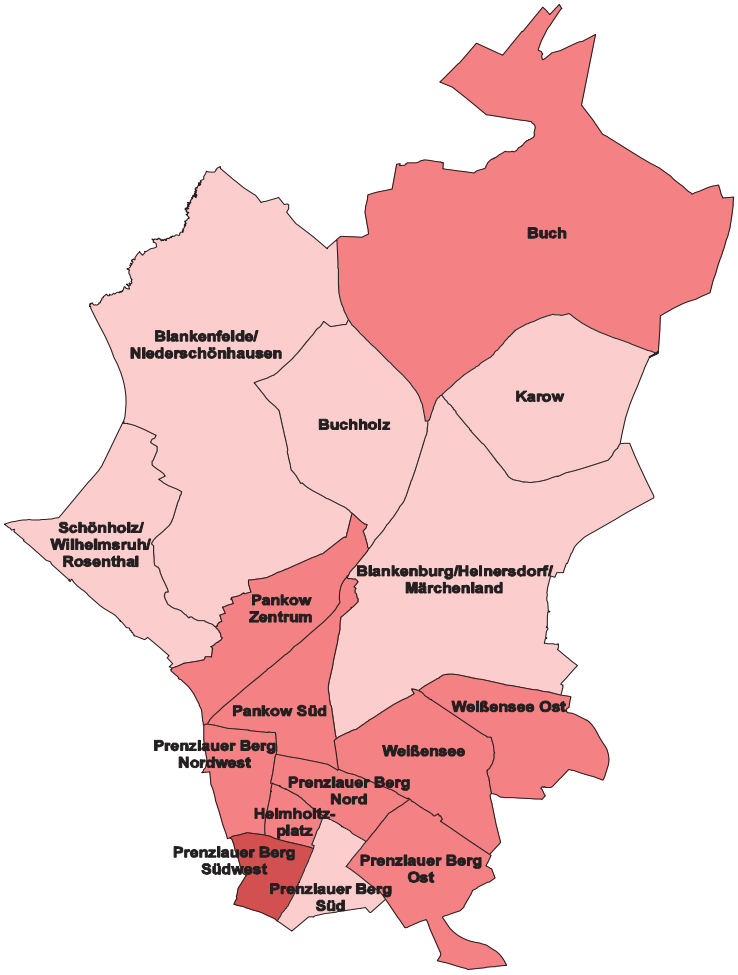

Häufigkeitszahl (HZ) -Jahr 2013

- unter 600
- 600 bis unter 1.000
- 1.000 bis unter 1.400
- 1.400 bis unter 1.800
- 1.800 und mehr

Körperverletzung -insgesamt (PKS-Schlüssel 220000)

Bezirksregion	Jahr 2012		Jahr 2013		Zu-/Abnahme			
	erfasste Fälle	HZ	erfasste Fälle	HZ	Fälle absolut	Fälle in %	HZ absolut	HZ in %
Buch	154	1 181	119	878	- 35	- 22,7	- 303	- 25,7
Blankenfelde/Niederschönhausen	136	537	126	485	- 10	- 7,4	- 52	- 9,7
Buchholz	71	423	75	441	4	x	18	(4,3)
Karow	44	235	106	569	62	x	334	(142,1)
Blankenburg/Heinersdorf	74	524	66	467	- 8	x	- 57	(- 10,9)
Pankow Süd	204	641	226	696	22	10,8	55	8,6
Schönholz/Wilhelmsruh/Rosenthal	79	461	60	350	- 19	x	- 111	(- 24,1)
Pankow Zentrum	212	653	221	663	9	4,2	10	1,5
Weißensee	308	935	278	827	- 30	- 9,7	- 108	- 11,6
Weißensee Ost	103	687	146	965	43	41,7	278	40,5
Prenzlauer Berg Nordwest	228	965	208	858	- 20	- 8,8	- 107	- 11,1
Prenzlauer Berg Nord	159	616	202	774	43	27,0	158	25,6
Helmholtzplatz	189	891	148	683	- 41	- 21,7	- 208	- 23,3
Prenzlauer Berg Ost	240	988	243	980	3	1,3	- 8	- 0,8
Prenzlauer Berg Südwest	344	1 419	325	1 310	- 19	- 5,5	- 109	- 7,7
Prenzlauer Berg Süd	166	539	154	495	- 12	- 7,2	- 44	- 8,2
nicht zuzuordnen	79		90					

Bezirk Berlin Charlottenburg-Wilmersdorf

Körperverletzung -insgesamt (Häufigkeitszahl)

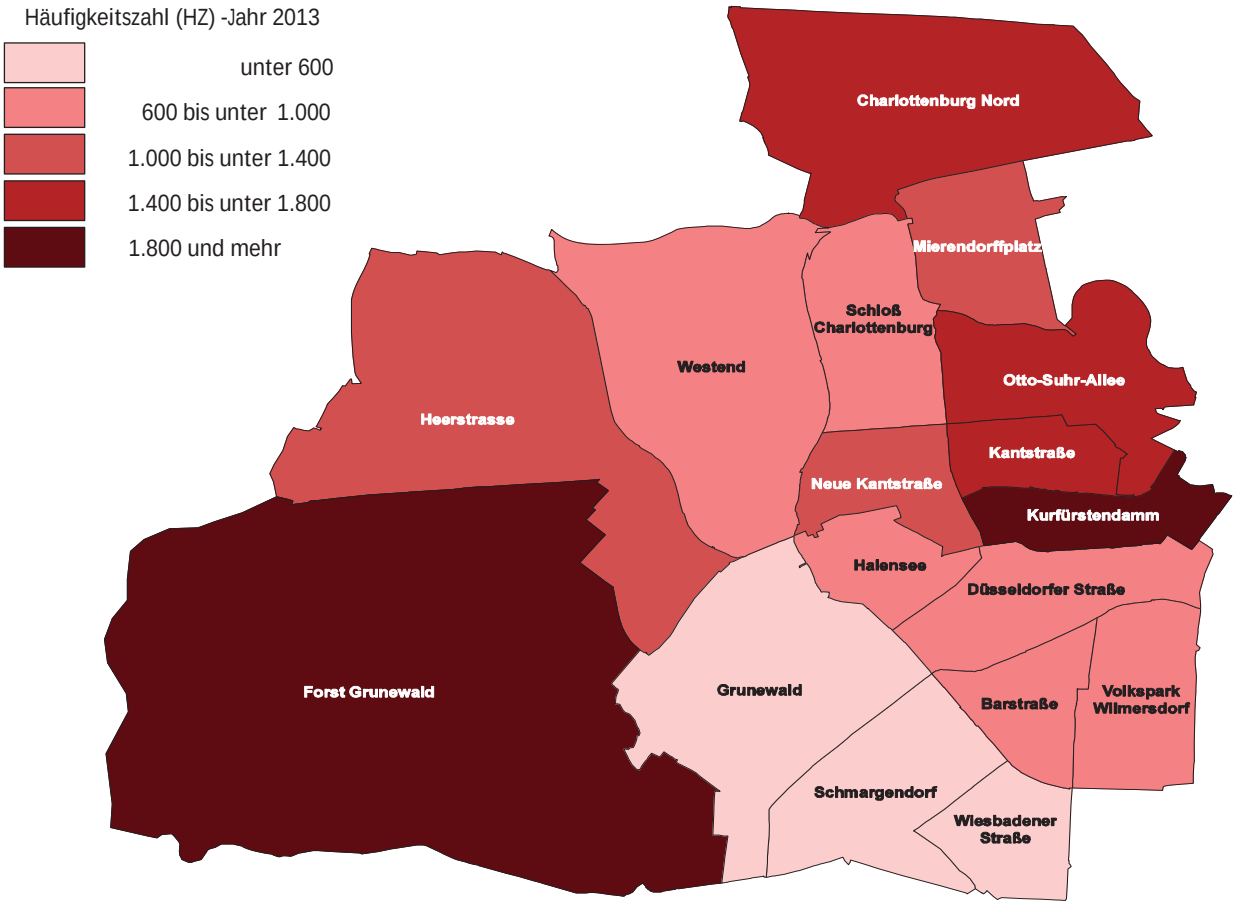

Körperverletzung -insgesamt (PKS-Schlüssel 220000)

Bezirksregion	Jahr 2012		Jahr 2013		Zu-/Abnahme			
	erfasste Fälle	HZ	erfasste Fälle	HZ	Fälle absolut	Fälle in %	HZ absolut	HZ in %
Charlottenburg Nord.....	278	1 537	298	1 614	20	7,2	77	5,0
Heerstraße.....	213	1 704	127	1 007	- 86	- 40,4	- 697	- 40,9
Westend.....	207	791	192	721	- 15	- 7,2	- 70	- 8,8
Schloß Charlottenburg.....	243	1 050	205	875	- 38	- 15,6	- 175	- 16,7
Mierendorffplatz.....	165	1 160	146	1 001	- 19	- 11,5	- 159	- 13,7
Otto-Suhr-Allee.....	421	1 652	385	1 493	- 36	- 8,6	- 159	- 9,6
Neue Kantstraße.....	164	715	247	1 066	83	50,6	351	49,1
Kantstraße.....	251	1 226	295	1 424	44	17,5	198	16,2
Kurfürstendamm.....	1 083	7 437	919	6 300	- 164	- 15,1	- 1 137	- 15,3
Halensee.....	137	965	135	936	- 2	- 1,5	- 29	- 3,0
Grunewald.....	98	547	96	527	- 2	x	- 20	(- 3,7)
Schmargendorf.....	82	594	72	518	- 10	x	- 76	(- 12,8)
Wiesbadener Straße.....	64	355	83	459	19	x	104	(29,3)
Düsseldorfer Straße.....	241	822	258	867	17	7,1	45	5,5
Barstraße.....	110	815	116	855	6	5,5	40	4,9
Volkspark Wilmersdorf.....	252	779	227	692	- 25	- 9,9	- 87	- 11,2
Forst Grunewald.....	10		15		5	x		x
nicht zuzuordnen.....	205		182					

Bezirk Berlin Spandau

Körperverletzung -insgesamt (Häufigkeitszahl)

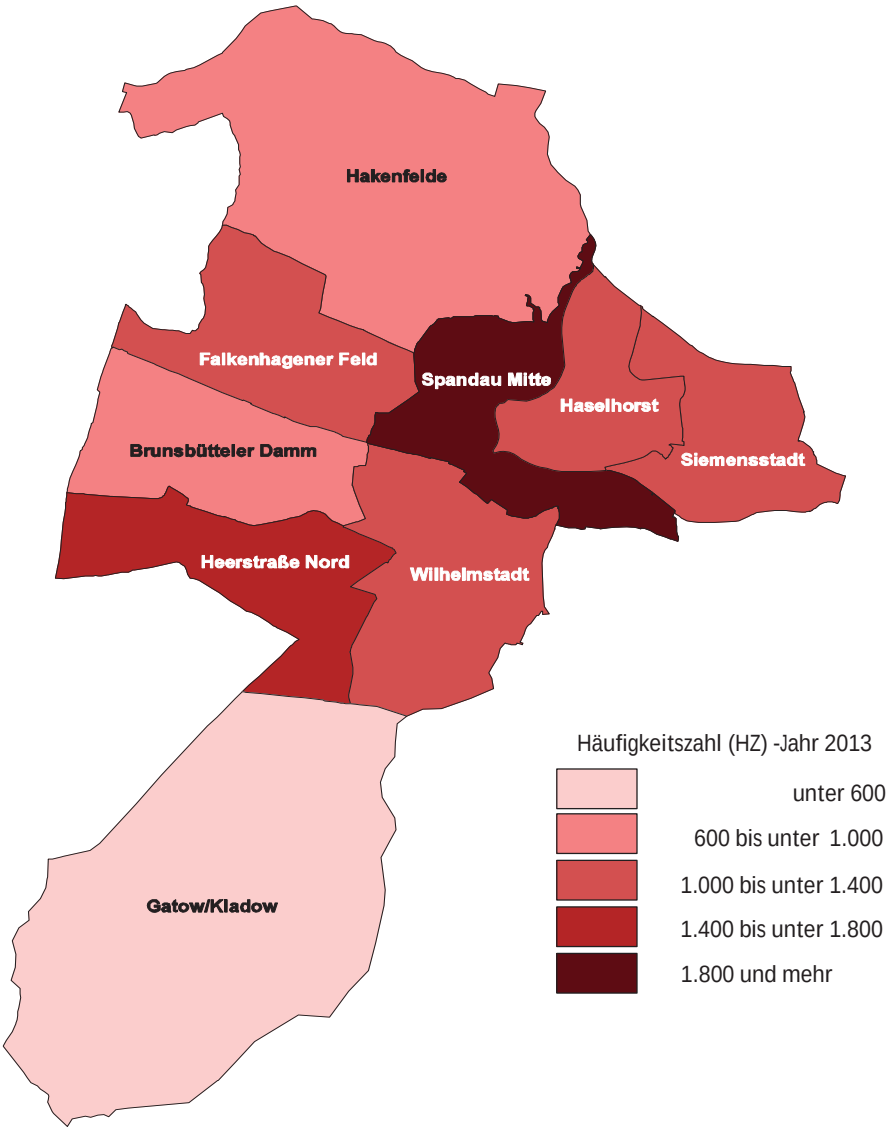

Körperverletzung -insgesamt (PKS-Schlüssel 220000)

Bezirksregion	Jahr 2012		Jahr 2013		Zu-/Abnahme			
	erfasste Fälle	HZ	erfasste Fälle	HZ	Fälle absolut	Fälle in %	HZ absolut	HZ in %
Hakenfelde.....	225	993	172	757	- 53	- 23,6	- 236	- 23,8
Falkenhagener Feld.....	432	1 107	445	1 135	13	3,0	28	2,5
Spandau Mitte.....	692	2 106	758	2 249	66	9,5	143	6,8
Brunsbütteler Damm.....	172	743	167	722	- 5	- 2,9	- 21	- 2,8
Heerstraße Nord.....	399	1 495	377	1 408	- 22	- 5,5	- 87	- 5,8
Wilhelmstadt.....	472	1 393	478	1 391	6	1,3	- 2	- 0,1
Haselhorst.....	165	1 199	156	1 081	- 9	- 5,5	- 118	- 9,8
Siemensstadt.....	168	1 445	158	1 318	- 10	- 6,0	- 127	- 8,8
Gatow/Kladow.....	76	428	70	386	- 6	x	- 42	(- 9,8)
nicht zuzuordnen.....	47		36					

Bezirk Berlin Steglitz-Zehlendorf

Körperverletzung -insgesamt (Häufigkeitszahl)

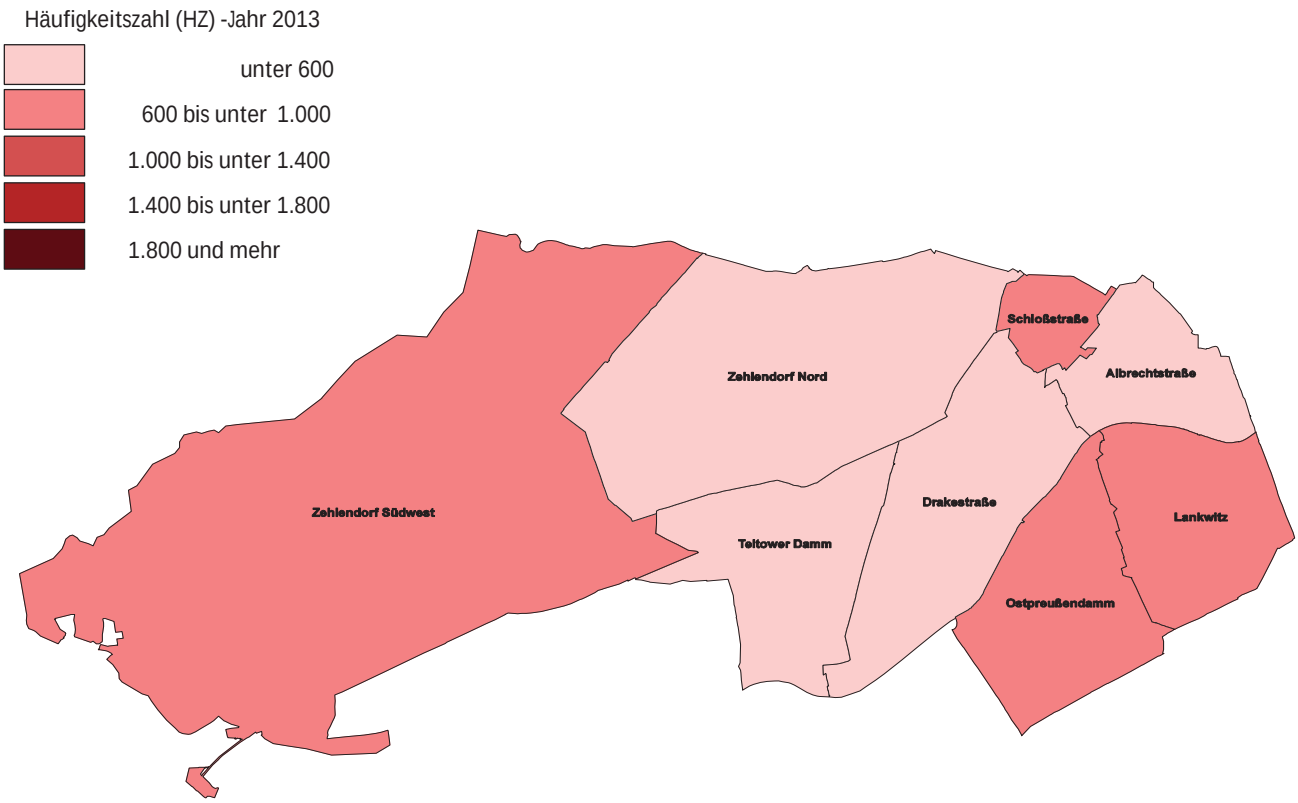

Körperverletzung -insgesamt (PKS-Schlüssel 220000)

Bezirksregion	Jahr 2012		Jahr 2013		Zu-/Abnahme			
	erfasste Fälle	HZ	erfasste Fälle	HZ	Fälle absolut	Fälle in %	HZ absolut	HZ in %
Schloßstraße	217	1 014	205	948	- 12	- 5,5	- 66	- 6,5
Albrechtstraße	258	503	263	508	5	1,9	5	1,0
Lankwitz	268	648	311	744	43	16,0	96	14,8
Ostpreußendamm	213	615	232	663	19	8,9	48	7,8
Teltower Damm	151	462	153	467	2	1,3	5	1,1
Drakestraße	206	451	198	426	- 8	- 3,9	- 25	- 5,5
Zehlendorf Südwest	141	553	161	630	20	14,2	77	13,9
Zehlendorf Nord	259	624	219	528	- 40	- 15,4	- 96	- 15,4
nicht zuzuordnen	39		44					

Bezirk Berlin Tempelhof-Schöneberg

Körperverletzung -insgesamt (Häufigkeitszahl)

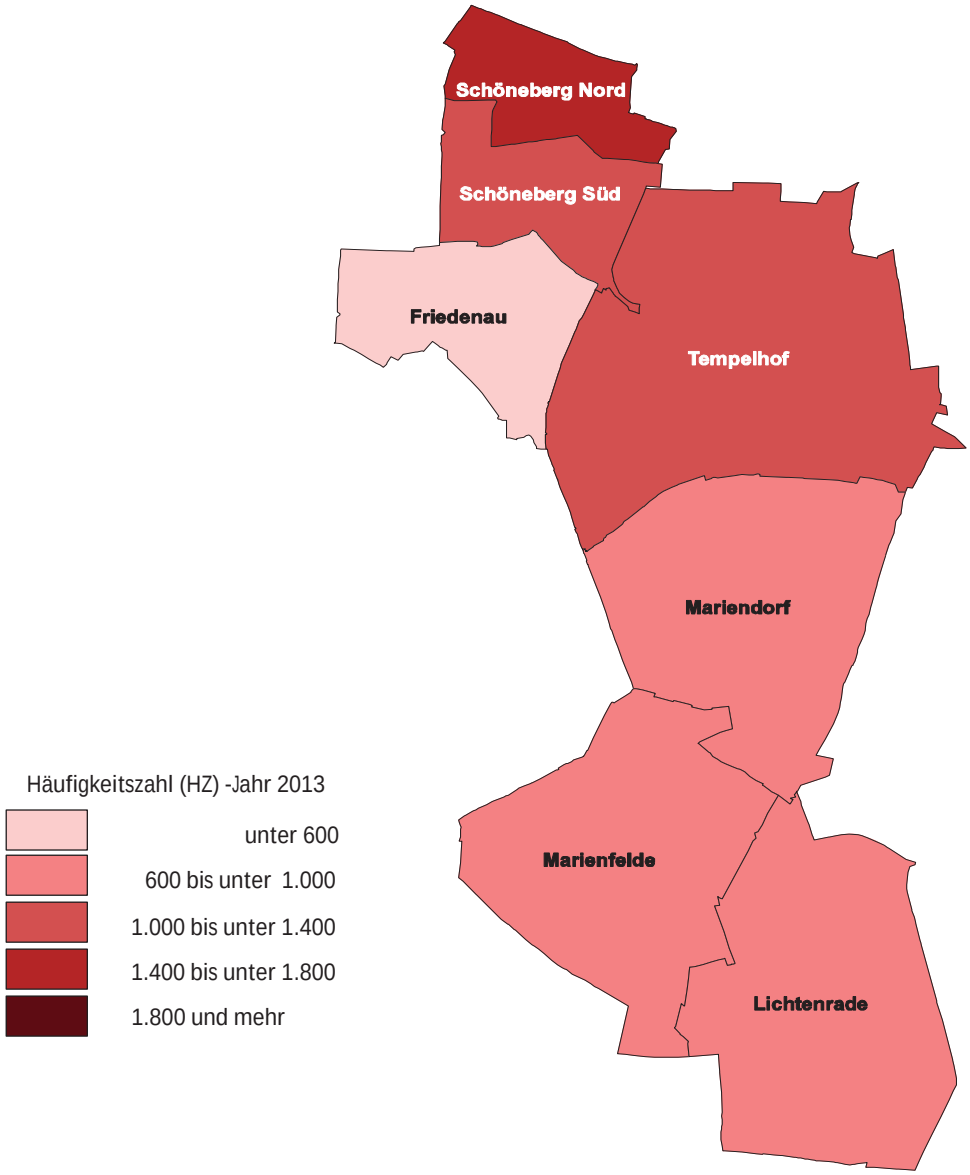

Körperverletzung -insgesamt (PKS-Schlüssel 220000)

Bezirksregion	Jahr 2012		Jahr 2013		Zu-/Abnahme			
					Fälle		HZ	
	erfasste Fälle	HZ	erfasste Fälle	HZ	absolut	in %	absolut	in %
Schöneberg Nord.....	772	1 639	786	1 674	14	1,8	35	2,1
Schöneberg Süd.....	510	1 073	548	1 149	38	7,5	76	7,1
Friedenau.....	306	695	259	583	- 47	- 15,4	- 112	- 16,1
Tempelhof.....	581	986	659	1 098	78	13,4	112	11,4
Mariendorf.....	367	737	417	834	50	13,6	97	13,2
Marienfelde.....	252	828	243	796	- 9	- 3,6	- 32	- 3,9
Lichtenrade.....	322	651	339	682	17	5,3	31	4,8
nicht zuzuordnen.....	106		69					

Bezirk Berlin Neukölln

Körperverletzung -insgesamt (Häufigkeitszahl)

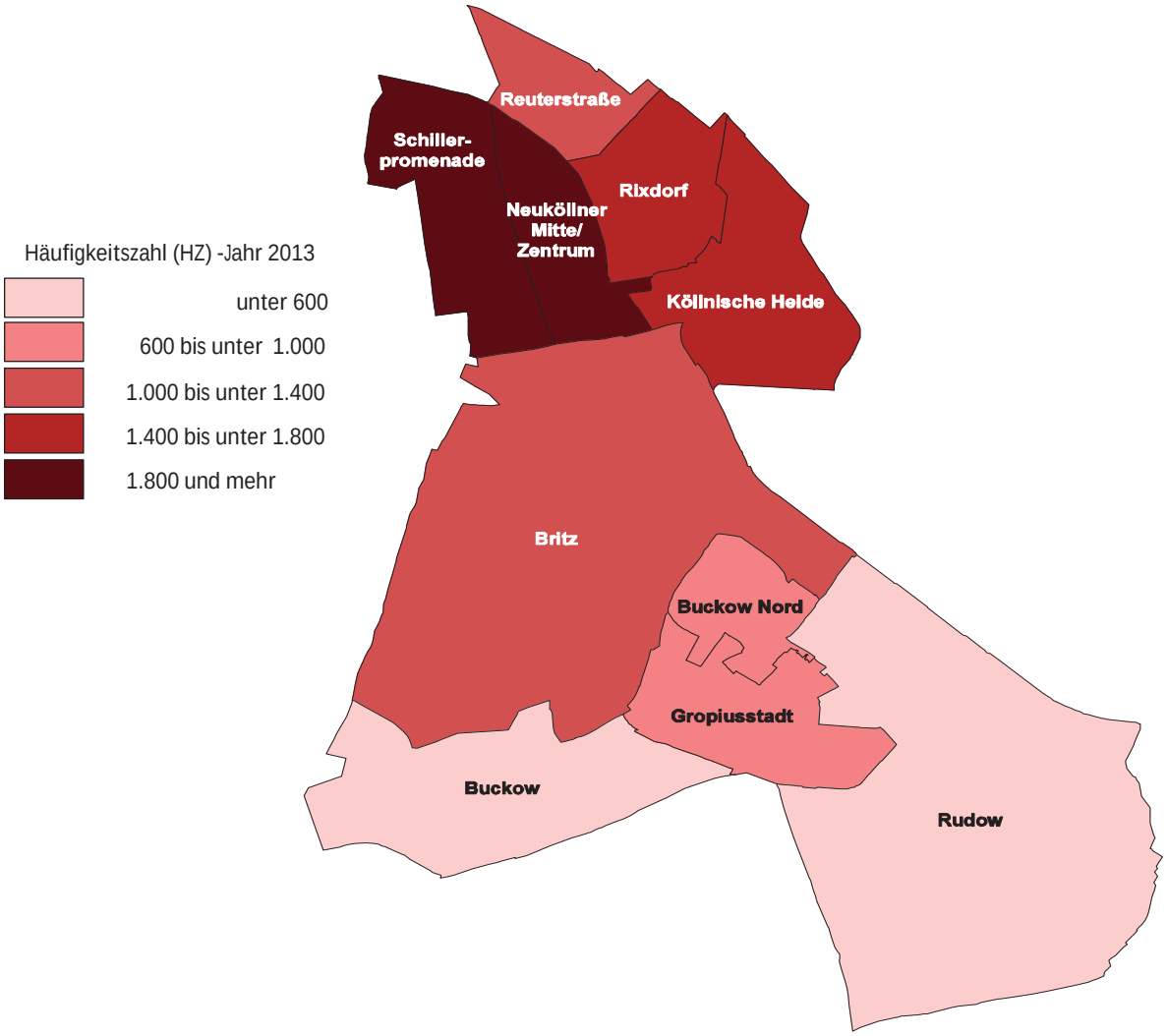

Körperverletzung -insgesamt (PKS-Schlüssel 220000)

Bezirksregion	Jahr 2012		Jahr 2013		Zu-/Abnahme			
	erfasste Fälle	HZ	erfasste Fälle	HZ	Fälle absolut	Fälle in %	HZ absolut	HZ in %
Schillerpromenade.....	676	2 186	679	2 151	3	0,4	- 35	- 1,6
Neuköllner Mitte/Zentrum.....	944	2 559	843	2 234	- 101	- 10,7	- 325	- 12,7
Reuterstraße.....	589	1 517	509	1 280	- 80	- 13,6	- 237	- 15,6
Rixdorf.....	605	1 557	603	1 526	- 2	- 0,3	- 31	- 2,0
Köllnische Heide.....	251	1 703	231	1 536	- 20	- 8,0	- 167	- 9,8
Britz.....	420	1 037	427	1 039	7	1,7	2	0,2
Buckow.....	206	746	138	496	- 68	- 33,0	- 250	- 33,5
Gropiusstadt.....	350	971	274	754	- 76	- 21,7	- 217	- 22,3
Buckow Nord.....	65	699	88	939	23	x	240	(34,3)
Rudow.....	206	491	230	546	24	11,7	55	11,2
nicht zuzuordnen.....	56		57					

Bezirk Berlin Treptow-Köpenick

Körperverletzung -insgesamt (Häufigkeitszahl)

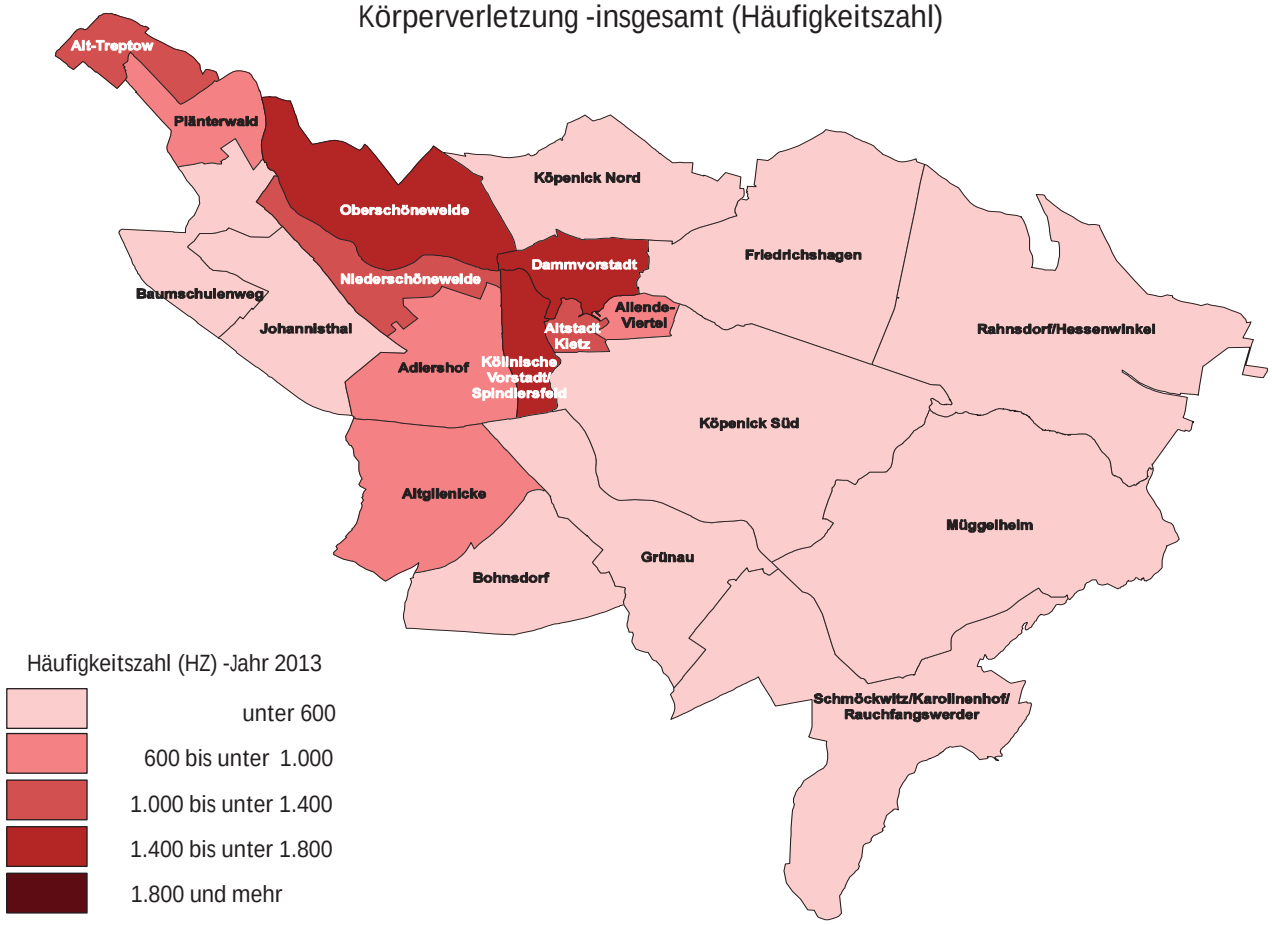

Körperverletzung -insgesamt (PKS-Schlüssel 220000)

Bezirksregion	Jahr 2012		Jahr 2013		Zu-/Abnahme			
	erfasste Fälle	HZ	erfasste Fälle	HZ	Fälle absolut	Fälle in %	HZ absolut	HZ in %
Alt-Treptow	136	1 245	127	1 144	- 9	- 6,6	- 101	- 8,1
Plänterwald	63	584	82	757	19	x	173	(29,6)
Baumschulenweg	113	656	95	545	- 18	- 15,9	- 111	- 16,9
Johannisthal	95	519	99	537	4	x	18	(3,5)
Oberschöneweide	309	1 612	353	1 790	44	14,2	178	11,0
Niederschöneweide	150	1 436	145	1 364	- 5	- 3,3	- 72	- 5,0
Adlershof	133	864	118	756	- 15	- 11,3	- 108	- 12,5
Kölln. Vorstadt/Spindlersf.	122	1 239	143	1 429	21	17,2	190	15,3
Altglienicke	149	583	164	634	15	10,1	51	8,7
Bohnsdorf	61	512	66	547	5	x	35	(6,8)
Grünau	31	574	22	393	- 9	x	- 181	(- 31,5)
Schmöckwitz/Karolinenhof	13	320	21	521	8	x	201	(62,8)
Köpenick Süd	65	416	73	469	8	x	53	(12,7)
Allende-Viertel	37	606	38	621	1	x	15	(2,5)
Altstadt Kietz	75	1 092	94	1 354	19	x	262	(24,0)
Müggelheim	10	154	14	214	4	x	60	(39,0)
Friedrichshagen	64	366	73	418	9	x	52	(14,2)
Rahnsdorf/Hessenwinkel	26	290	25	279	- 1	x	- 11	(- 3,8)
Dammvorstadt	122	1 295	139	1 460	17	13,9	165	12,7
Köpenick Nord	45	366	38	310	- 7	x	- 56	(- 15,3)
nicht zuzuordnen	104		80					

Bezirk Berlin Marzahn-Hellersdorf

Körperverletzung -insgesamt (Häufigkeitszahl)

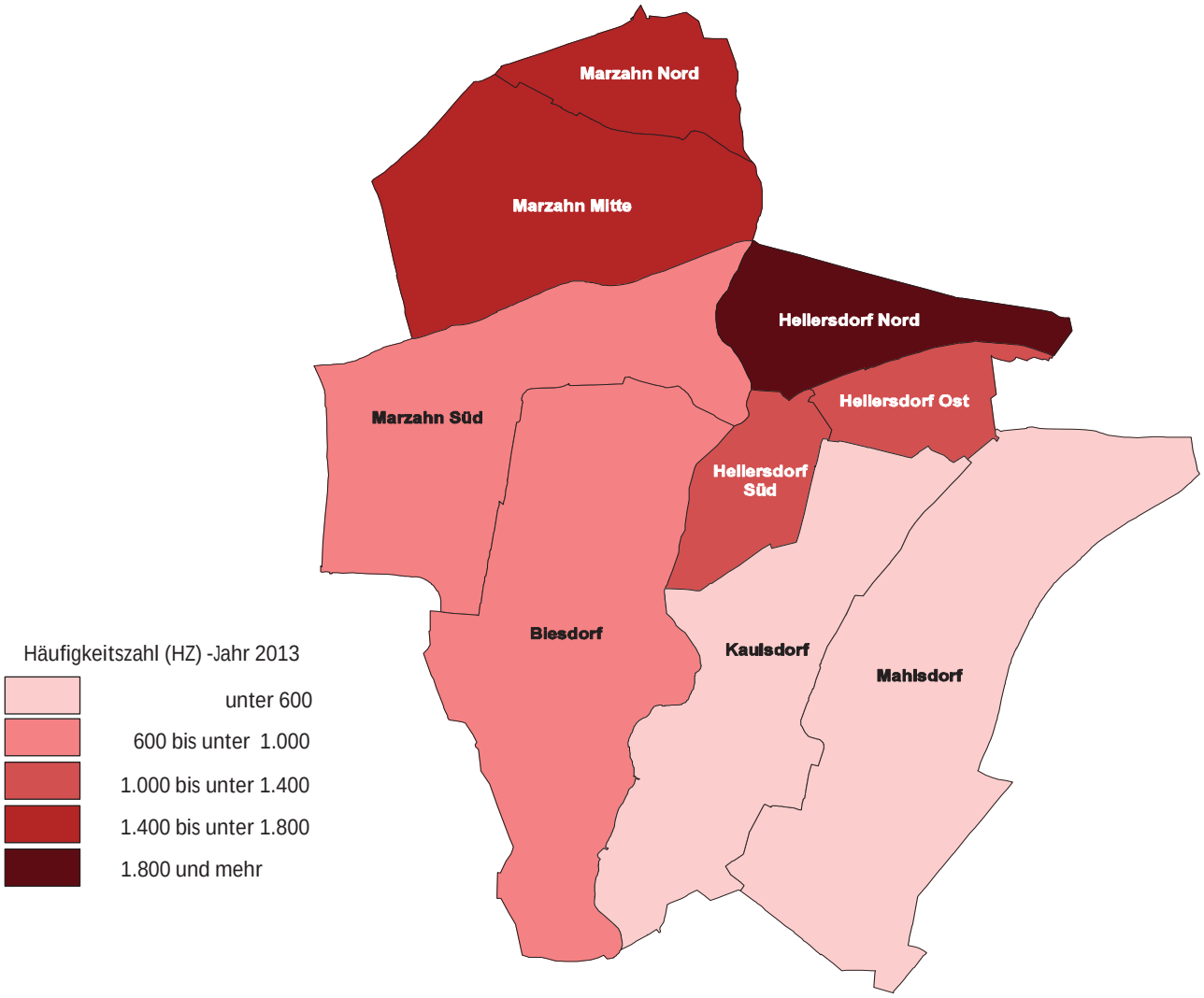

Körperverletzung -insgesamt (PKS-Schlüssel 220000)

Bezirksregion	Jahr 2012		Jahr 2013		Zu-/Abnahme			
	erfasste Fälle	HZ	erfasste Fälle	HZ	Fälle absolut	Fälle in %	HZ absolut	HZ in %
Marzahn Nord	442	1 951	402	1 753	- 40	- 9,0	- 198	- 10,1
Marzahn Mitte	721	1 595	782	1 714	61	8,5	119	7,5
Marzahn Süd	295	817	340	929	45	15,3	112	13,7
Hellersdorf Nord	652	1 988	717	2 153	65	10,0	165	8,3
Hellersdorf Ost	289	1 567	205	1 086	- 84	- 29,1	- 481	- 30,7
Hellersdorf Süd	223	919	286	1 171	63	28,3	252	27,4
Biesdorf	141	561	177	694	36	25,5	133	23,7
Kaulsdorf	110	588	71	381	- 39	- 35,5	- 207	- 35,2
Mahlsdorf	89	330	86	317	- 3	x	- 13	(- 3,9)
nicht zuzuordnen	90		73					

Bezirk Berlin Lichtenberg

Körperverletzung -insgesamt (Häufigkeitszahl)

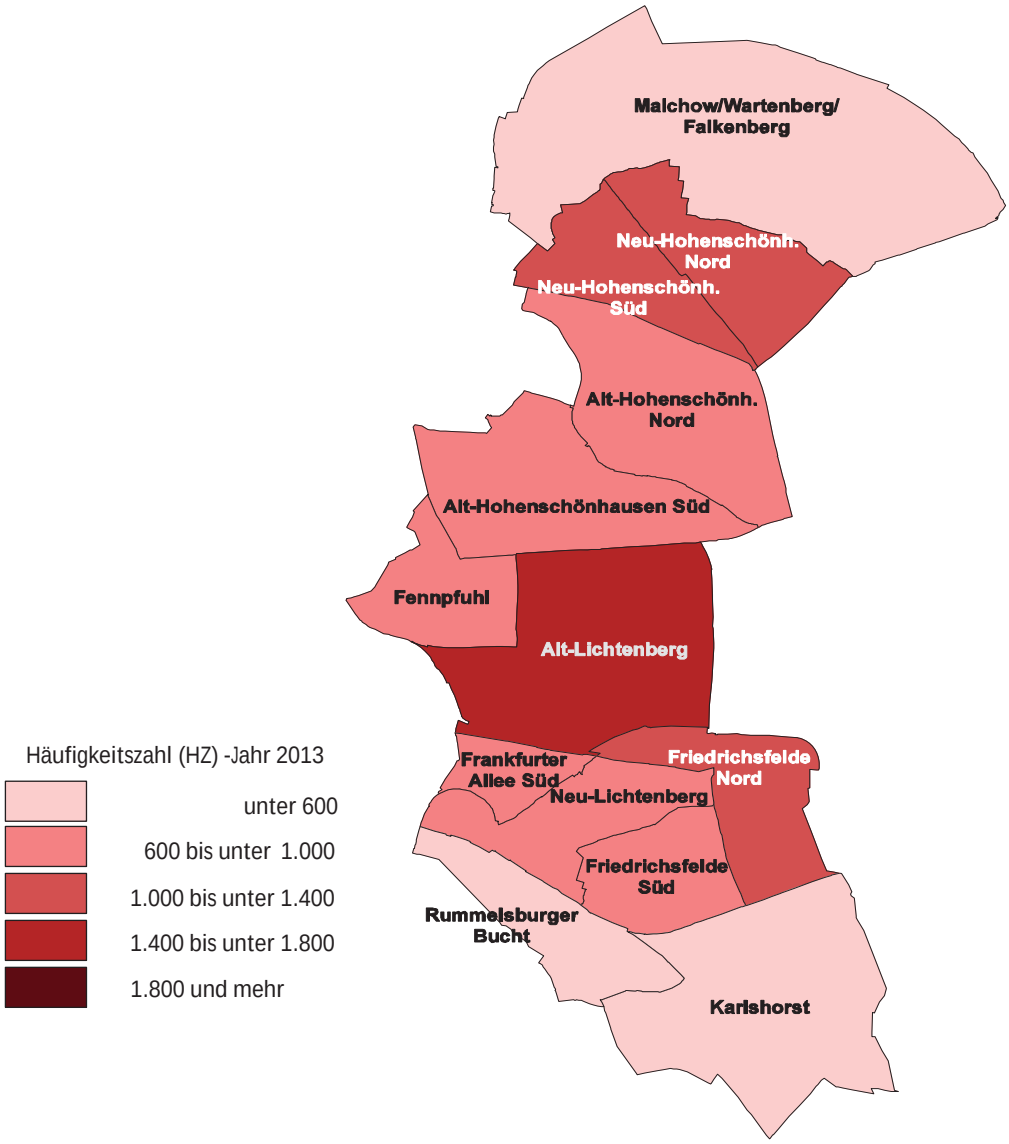

Körperverletzung -insgesamt (PKS-Schlüssel 220000)

Bezirksregion	Jahr 2012		Jahr 2013		Zu-/Abnahme			
	erfasste Fälle	HZ	erfasste Fälle	HZ	Fälle		HZ	
					absolut	in %	absolut	in %
Malchow/Warten-/Falkenberg.....	26	620	23	541	- 3	x	- 79	(- 12,7)
Neu-Hohenschönhausen Nord.....	328	1 193	333	1 203	5	1,5	10	0,8
Neu-Hohenschönhausen Süd.....	330	1 275	287	1 110	- 43	- 13,0	- 165	- 12,9
Alt-Hohenschönhausen Nord.....	134	995	117	867	- 17	- 12,7	- 128	- 12,9
Alt-Hohenschönhausen Süd.....	234	796	206	699	- 28	- 12,0	- 97	- 12,2
Fennpfuhl.....	284	895	257	803	- 27	- 9,5	- 92	- 10,3
Alt-Lichtenberg.....	350	1 457	372	1 492	22	6,3	35	2,4
Frankfurter Allee Süd.....	67	694	90	898	23	x	204	(29,4)
Neu-Lichtenberg.....	284	967	246	819	- 38	- 13,4	- 148	- 15,3
Friedrichsfelde Nord.....	174	1 306	147	1 087	- 27	- 15,5	- 219	- 16,8
Friedrichsfelde Süd.....	159	659	161	655	2	1,3	- 4	- 0,6
Rummelsburger Bucht.....	18	552	19	573	1	x	21	(3,8)
Karlshorst.....	95	421	111	476	16	x	55	(13,1)
nicht zuzuordnen.....	87		64					

Bezirk Berlin Reinickendorf

Körperverletzung -insgesamt (Häufigkeitszahl)

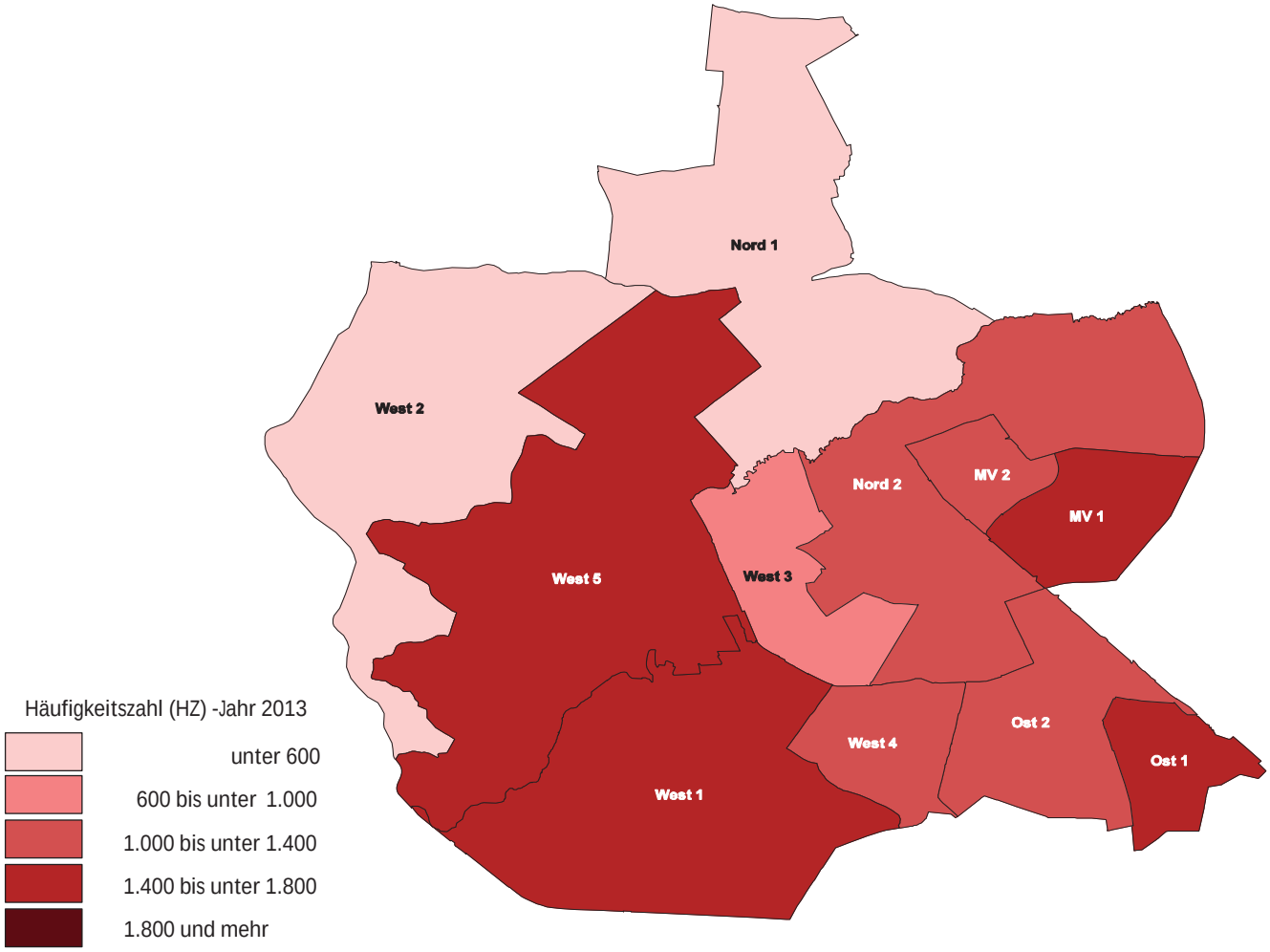

Körperverletzung -insgesamt (PKS-Schlüssel 220000)

Bezirksregion	Jahr 2012		Jahr 2013		Zu-/Abnahme			
	erfasste Fälle	HZ	erfasste Fälle	HZ	Fälle absolut	Fälle in %	HZ absolut	HZ in %
Ost 1	400	1 559	393	1 512	- 7	- 1,8	- 47	- 3,0
Ost 2	290	1 137	313	1 211	23	7,9	74	6,5
West 1	271	1 863	228	1 576	- 43	- 15,9	- 287	- 15,4
West 4	376	1 504	342	1 345	- 34	- 9,0	- 159	- 10,6
West 5	233	2 281	158	1 535	- 75	- 32,2	- 746	- 32,7
West 2	89	378	90	379	1	x	1	(0,3)
Nord 1	116	355	117	357	1	0,9	2	0,6
Nord 2	332	1 137	310	1 041	- 22	- 6,6	- 96	- 8,4
MV 1	490	1 384	600	1 649	110	22,4	265	19,1
MV 2	103	1 257	85	1 000	- 18	- 17,5	- 257	- 20,4
West 3	145	908	121	757	- 24	- 16,6	- 151	- 16,6
nicht zuzuordnen	31		23					

Berlin - Schwere und gefährliche Körperverletzung (Häufigkeitszahl)

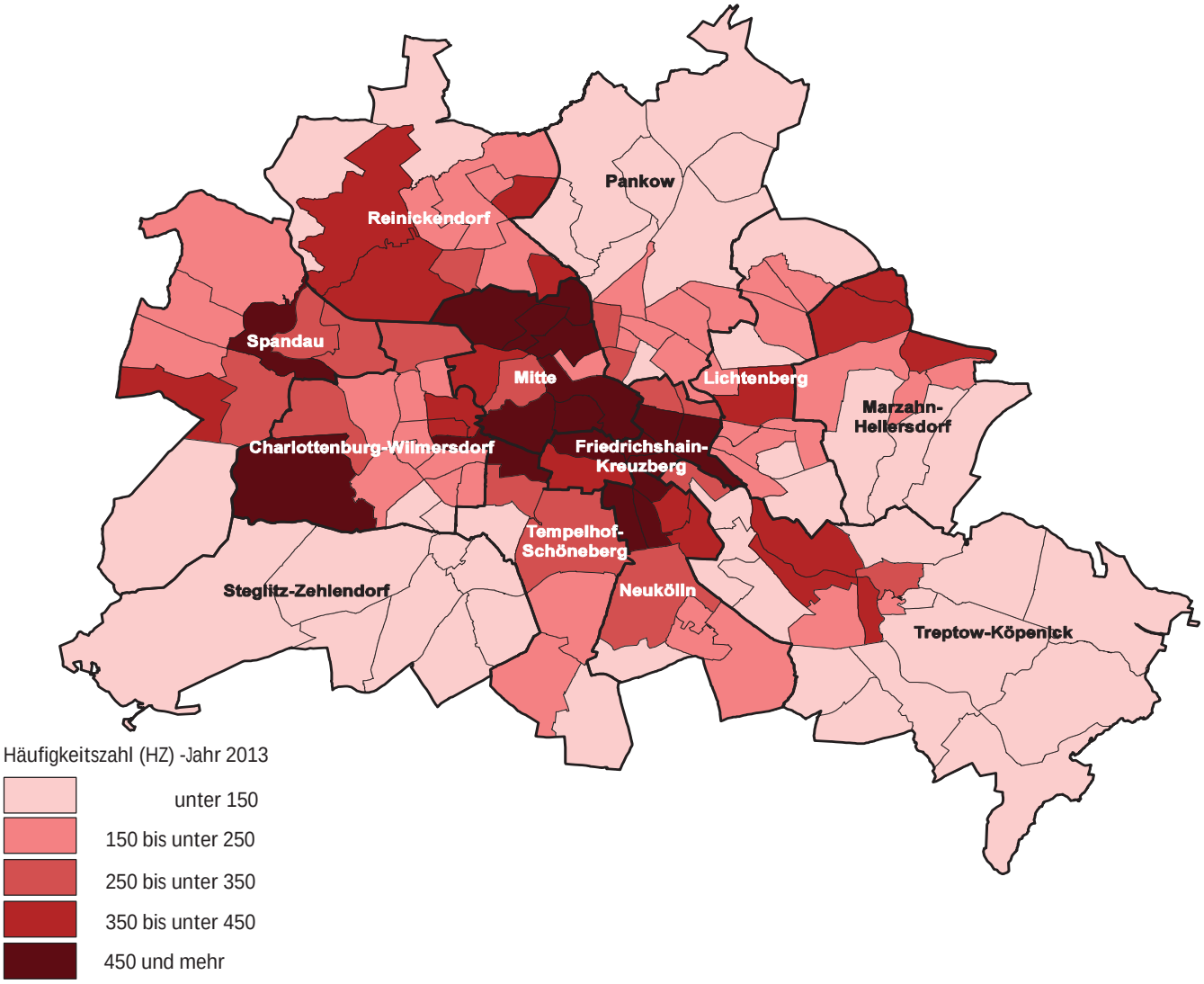

Schwere und gefährliche Körperverletzung (PKS-Schlüssel 222000)

Bezirk	Jahr 2012		Jahr 2013		Zu-/Abnahme			
	erfasste Fälle	HZ	erfasste Fälle	HZ	Fälle absolut	Fälle in %	HZ absolut	HZ in %
Mitte	2 362	704	1 966	572	- 396	- 16,8	- 132	- 18,8
Friedrichshain-Kreuzberg	1 383	518	1 437	530	54	3,9	12	2,3
Pankow	687	187	632	169	- 55	- 8,0	- 18	- 9,6
Charlottenburg-Wilmersdorf	1 195	377	1 049	327	- 146	- 12,2	- 50	- 13,3
Spandau	700	316	661	294	- 39	- 5,6	- 22	- 7,0
Steglitz-Zehlendorf	348	118	337	114	- 11	- 3,2	- 4	- 3,4
Tempelhof-Schöneberg	735	225	808	245	73	9,9	20	8,9
Neukölln	1 272	403	1 191	372	- 81	- 6,4	- 31	- 7,7
Treptow-Köpenick	426	176	435	178	9	2,1	2	1,1
Marzahn-Hellersdorf	625	250	615	243	- 10	- 1,6	- 7	- 2,8
Lichtenberg	586	227	500	190	- 86	- 14,7	- 37	- 16,3
Reinickendorf	713	290	616	247	- 97	- 13,6	- 43	- 14,8
Berlin, nicht zuzuordnen	96		94					
Berlin -Gesamt-	**11 128**	**330**	**10 341**	**304**	**- 787**	**-7,1**	**- 26**	**-8,0**

Bezirk Berlin Mitte

Schwere und gefährliche Körperverletzung (Häufigkeitszahl)

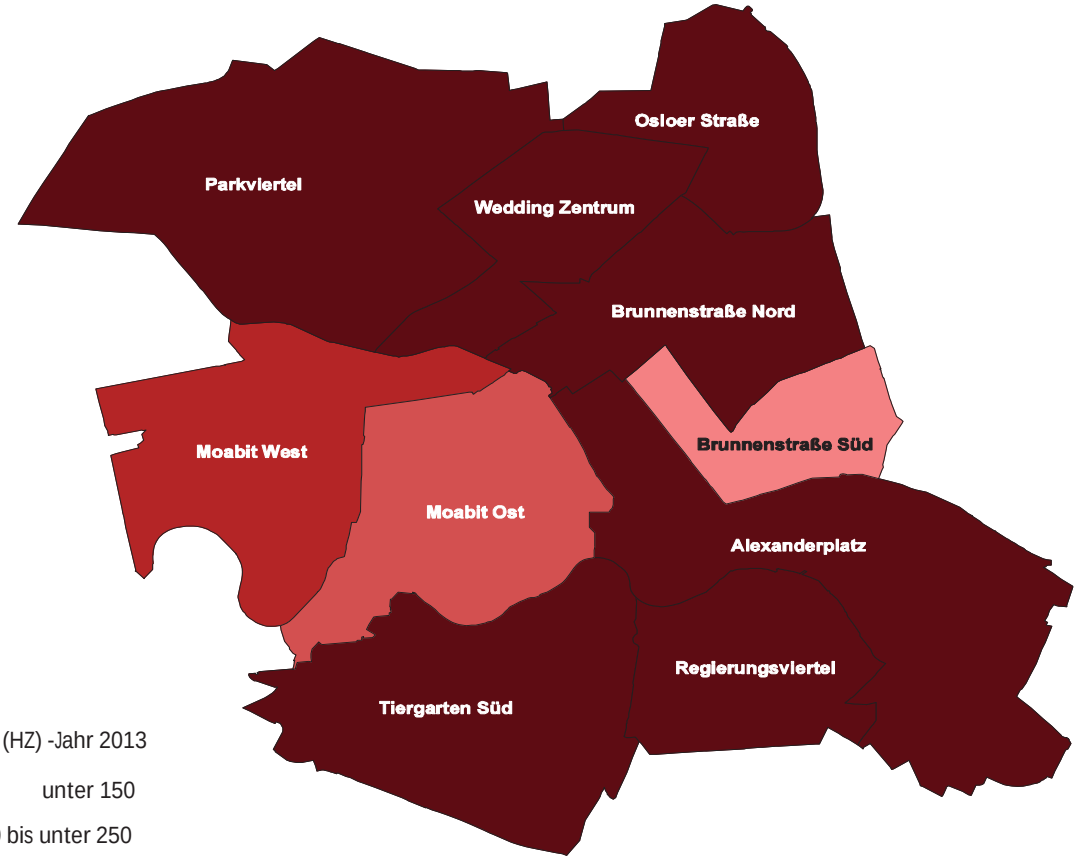

Häufigkeitszahl (HZ) -Jahr 2013

- unter 150
- 150 bis unter 250
- 250 bis unter 350
- 350 bis unter 450
- 450 und mehr

Schwere und gefährliche Körperverletzung (PKS-Schlüssel 222000)

Bezirksregion	Jahr 2012		Jahr 2013		Zu-/Abnahme			
	erfasste Fälle	HZ	erfasste Fälle	HZ	Fälle absolut	Fälle in %	HZ absolut	HZ in %
Tiergarten Süd	194	1 540	148	1 138	- 46	- 23,7	- 402	- 26,1
Regierungsviertel	123	1 342	120	1 291	- 3	- 2,4	- 51	- 3,8
Alexanderplatz	454	962	354	735	- 100	- 22,0	- 227	- 23,6
Brunnenstraße Süd	60	235	51	192	- 9	x	- 43	(-18,3)
Moabit West	185	442	156	365	- 29	- 15,7	- 77	- 17,4
Moabit Ost	147	422	122	345	- 25	- 17,0	- 77	- 18,2
Osloer Straße	223	636	210	580	- 13	- 5,8	- 56	- 8,8
Brunnenstraße Nord	192	544	164	458	- 28	- 14,6	- 86	- 15,8
Parkviertel	211	509	206	486	- 5	- 2,4	- 23	- 4,5
Wedding Zentrum	426	811	341	630	- 85	- 20,0	- 181	- 22,3
nicht zuzuordnen	147	-	94	-				

Bezirk Berlin Friedrichshain-Kreuzberg

Schwere und gefährliche Körperverletzung (Häufigkeitszahl)

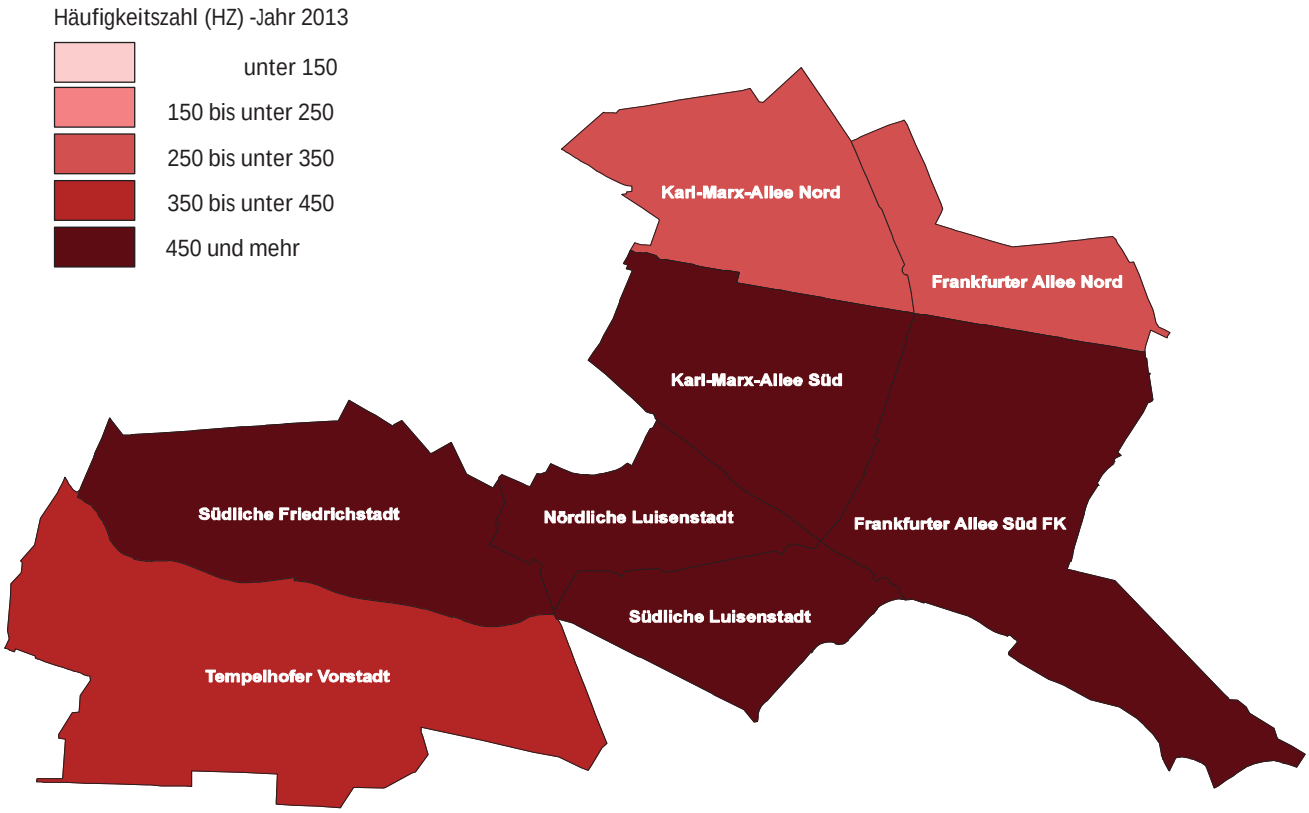

Schwere und gefährliche Körperverletzung (PKS-Schlüssel 222000)

Bezirksregion	Jahr 2012		Jahr 2013		Zu-/Abnahme			
					Fälle		HZ	
	erfasste Fälle	HZ	erfasste Fälle	HZ	absolut	in %	absolut	in %
Südliche Friedrichstadt.....	222	570	185	468	- 37	- 16,7	- 102	- 17,9
Tempelhofer Vorstadt.....	274	450	242	391	- 32	- 11,7	- 59	- 13,1
Nördliche Luisenstadt.....	153	685	192	852	39	25,5	167	24,4
Südliche Luisenstadt.....	138	529	199	753	61	44,2	224	42,3
Karl-Marx-Allee Nord.....	61	274	63	280	2	x	6	(2,2)
Karl-Marx-Allee Süd.....	123	536	144	615	21	17,1	79	14,7
Frankfurter Allee Nord.....	83	306	71	257	- 12	x	- 49	(- 16,0)
Frankfurter Allee Süd FK.....	276	597	297	628	21	7,6	31	5,2
nicht zuzuordnen.....	53		44					

Bezirk Berlin Pankow

Schwere und gefährliche Körperverletzung (Häufigkeitszahl)

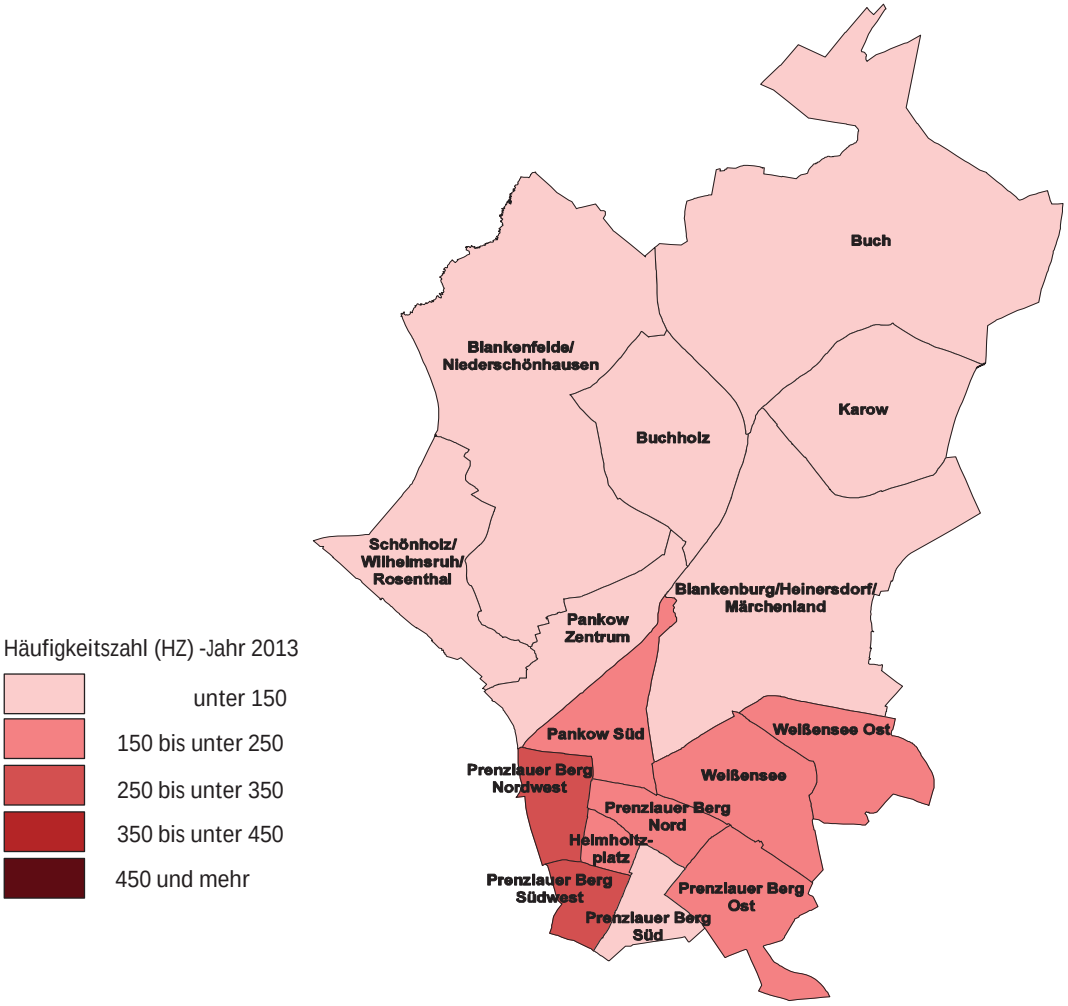

Schwere und gefährliche Körperverletzung (PKS-Schlüssel 222000)

Bezirksregion	Jahr 2012		Jahr 2013		Zu-/Abnahme			
	erfasste Fälle	HZ	erfasste Fälle	HZ	Fälle absolut	Fälle in %	HZ absolut	HZ in %
Buch	45	345	20	148	- 25	x	- 197	(- 57,1)
Blankenfelde/Niederschönhausen	27	107	28	108	1	x	1	(0,9)
Buchholz	13	77	19	112	6	x	35	x
Karow	6	32	19	102	13	x	70	x
Blankenburg/Heinersdorf	9	64	12	85	3	x	21	x
Pankow Süd	35	110	52	160	17	x	50	(45,5)
Schönholz/Wilhelmsruh/Rosenthal	24	140	13	76	- 11	x	- 64	(- 45,7)
Pankow Zentrum	62	191	47	141	- 15	x	- 50	(- 26,2)
Weißensee	78	237	56	167	- 22	x	- 70	(- 29,5)
Weißensee Ost	23	153	25	165	2	x	12	(7,8)
Prenzlauer Berg Nordwest	68	288	62	256	- 6	x	- 32	(- 11,1)
Prenzlauer Berg Nord	33	128	43	165	10	x	37	(28,9)
Helmholtzplatz	47	222	38	175	- 9	x	- 47	(- 21,2)
Prenzlauer Berg Ost	72	296	59	238	- 13	x	- 58	(- 19,6)
Prenzlauer Berg Südwest	92	380	86	347	- 6	x	- 33	(- 8,7)
Prenzlauer Berg Süd	30	97	33	106	3	x	9	x
nicht zuzuordnen	23		20					

Bezirk Berlin Charlottenburg-Wilmersdorf

Schwere und gefährliche Körperverletzung (Häufigkeitszahl)

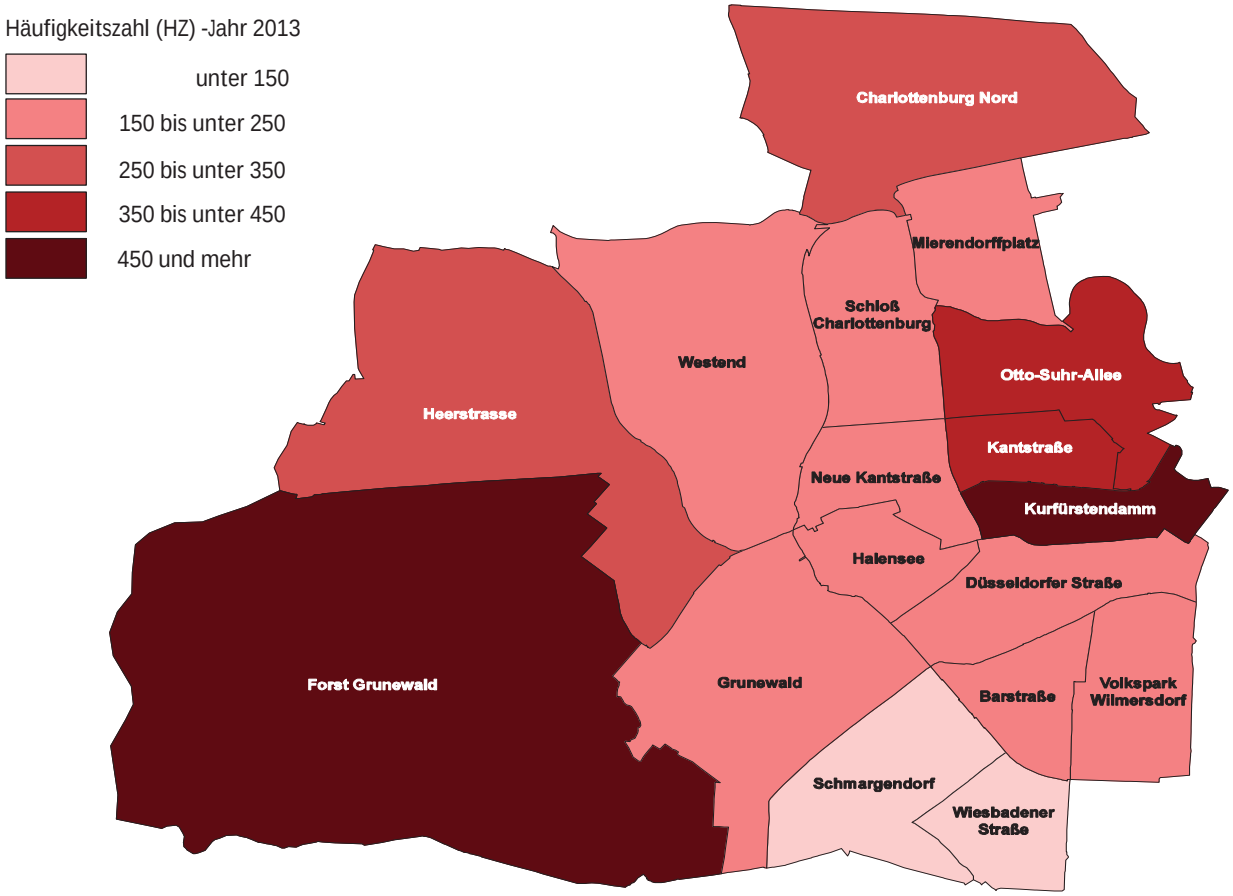

Schwere und gefährliche Körperverletzung (PKS-Schlüssel 222000)

Bezirksregion	Jahr 2012		Jahr 2013		Zu-/Abnahme			
	erfasste Fälle	HZ	erfasste Fälle	HZ	Fälle absolut	Fälle in %	HZ absolut	HZ in %
Charlottenburg Nord.....	73	404	64	347	- 9	x	- 57	(- 14,1)
Heerstraße.....	93	744	41	325	- 52	x	- 419	(- 56,3)
Westend.....	48	183	46	173	- 2	x	- 10	(- 5,5)
Schloß Charlottenburg.....	55	238	46	196	- 9	x	- 42	(- 17,6)
Mierendorffplatz.....	46	323	32	219	- 14	x	- 104	(- 32,2)
Otto-Suhr-Allee.....	113	444	98	380	- 15	- 13,3	- 64	- 14,4
Neue Kantstraße.....	39	170	55	237	16	x	67	(39,4)
Kantstraße.....	65	318	79	381	14	x	63	(19,8)
Kurfürstendamm.....	361	2 479	287	1 968	- 74	- 20,5	- 511	- 20,6
Halensee.....	29	204	25	173	- 4	x	- 31	(- 15,2)
Grunewald.....	11	61	28	154	17	x	93	x
Schmargendorf.....	18	130	14	101	- 4	x	- 29	(- 22,3)
Wiesbadener Straße.....	12	67	12	66		x	- 1	x
Düsseldorfer Straße.....	67	228	69	232	2	x	4	(1,8)
Barstraße.....	33	245	29	214	- 4	x	- 31	(- 12,7)
Volkspark Wilmersdorf.....	67	207	62	189	- 5	x	- 18	(- 8,7)
Forst Grunewald.....	3		5		2	x		x
nicht zuzuordnen.....	62		57					

Bezirk Berlin Spandau

Schwere und gefährliche Körperverletzung (Häufigkeitszahl)

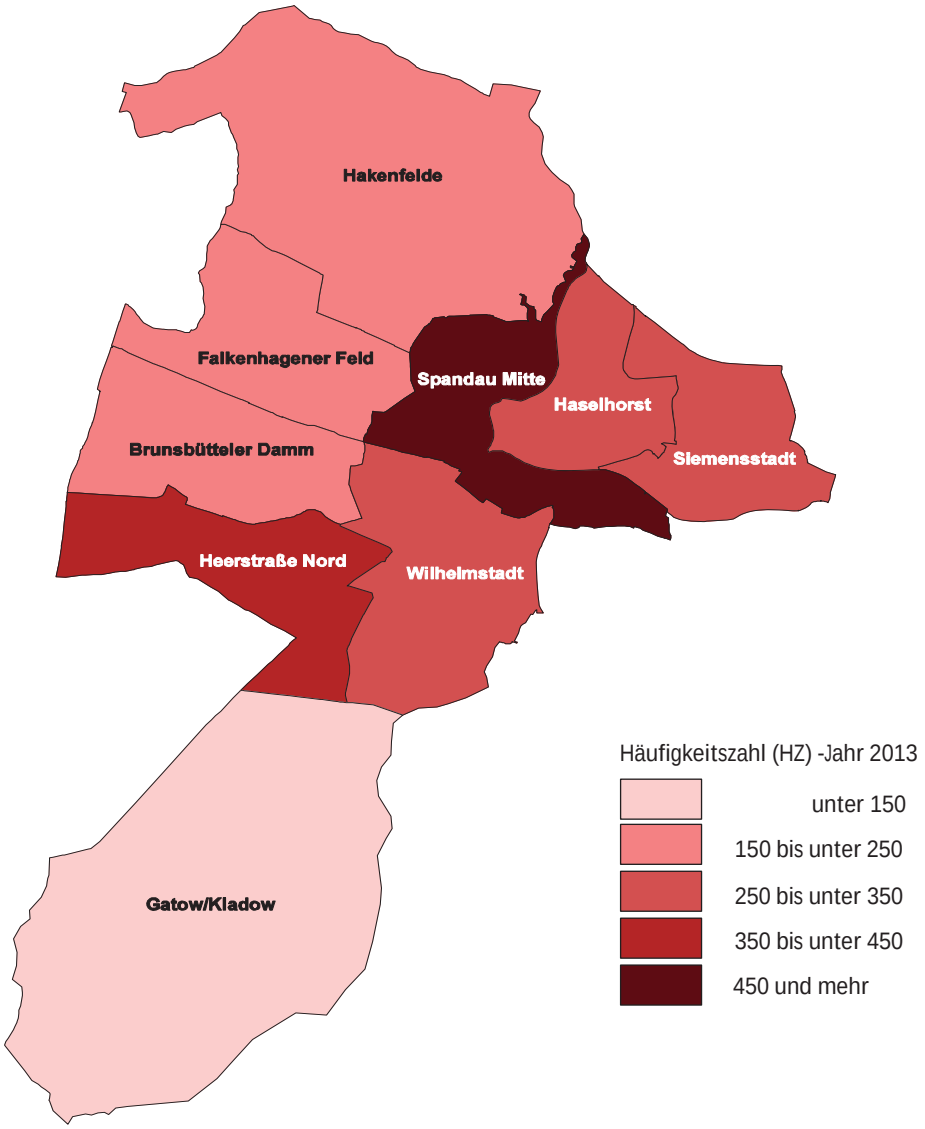

Schwere und gefährliche Körperverletzung (PKS-Schlüssel 222000)

Bezirksregion	Jahr 2012		Jahr 2013		Zu-/Abnahme			
	erfasste Fälle	HZ	erfasste Fälle	HZ	Fälle		HZ	
					absolut	in %	absolut	in %
Hakenfelde.....	49	216	42	185	- 7	x	- 31	(- 14,4)
Falkenhagener Feld.....	113	290	85	217	- 28	- 24,8	- 73	- 25,2
Spandau Mitte.....	192	584	181	537	- 11	- 5,7	- 47	- 8,0
Brunsbütteler Damm.....	41	177	44	190	3	x	13	(7,3)
Heerstraße Nord.....	95	356	102	381	7	x	25	(7,0)
Wilhelmstadt.....	116	342	111	323	- 5	- 4,3	- 19	- 5,6
Haselhorst.....	35	254	40	277	5	x	23	(9,1)
Siemensstadt.....	36	310	34	284	- 2	x	- 26	(- 8,4)
Gatow/Kladow.....	15	84	16	88	1	x	4	x
nicht zuzuordnen.....	8		6					

Bezirk Berlin Steglitz-Zehlendorf

Schwere und gefährliche Körperverletzung (Häufigkeitszahl)

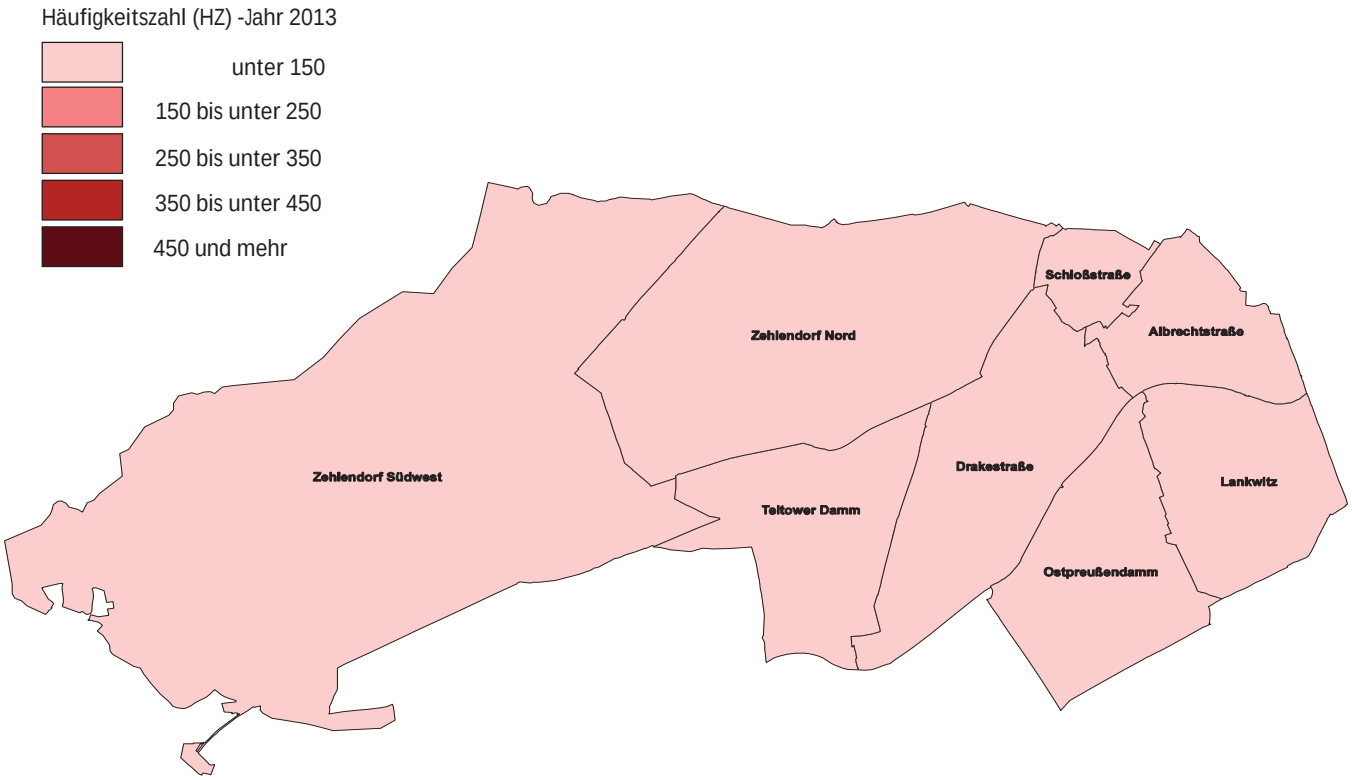

Schwere und gefährliche Körperverletzung (PKS-Schlüssel 222000)

Bezirksregion	Jahr 2012		Jahr 2013		Zu-/Abnahme			
	erfasste Fälle	HZ	erfasste Fälle	HZ	Fälle absolut	Fälle in %	HZ absolut	HZ in %
Schloßstraße	50	234	30	139	- 20	x	- 95	(- 40,6)
Albrechtstraße	29	56	52	100	23	x	44	x
Lankwitz	51	123	60	144	9	x	21	(17,1)
Ostpreußendamm	59	170	52	149	- 7	x	- 21	(- 12,4)
Teltower Damm	38	116	30	92	- 8	x	- 24	(- 20,7)
Drakestraße	33	72	33	71		x	- 1	x
Zehlendorf Südwest	21	82	28	110	7	x	28	x
Zehlendorf Nord	51	123	44	106	- 7	x	- 17	(- 13,8)
nicht zuzuordnen	16		8					

Bezirk Berlin Tempelhof-Schöneberg

Schwere und gefährliche Körperverletzung (Häufigkeitszahl)

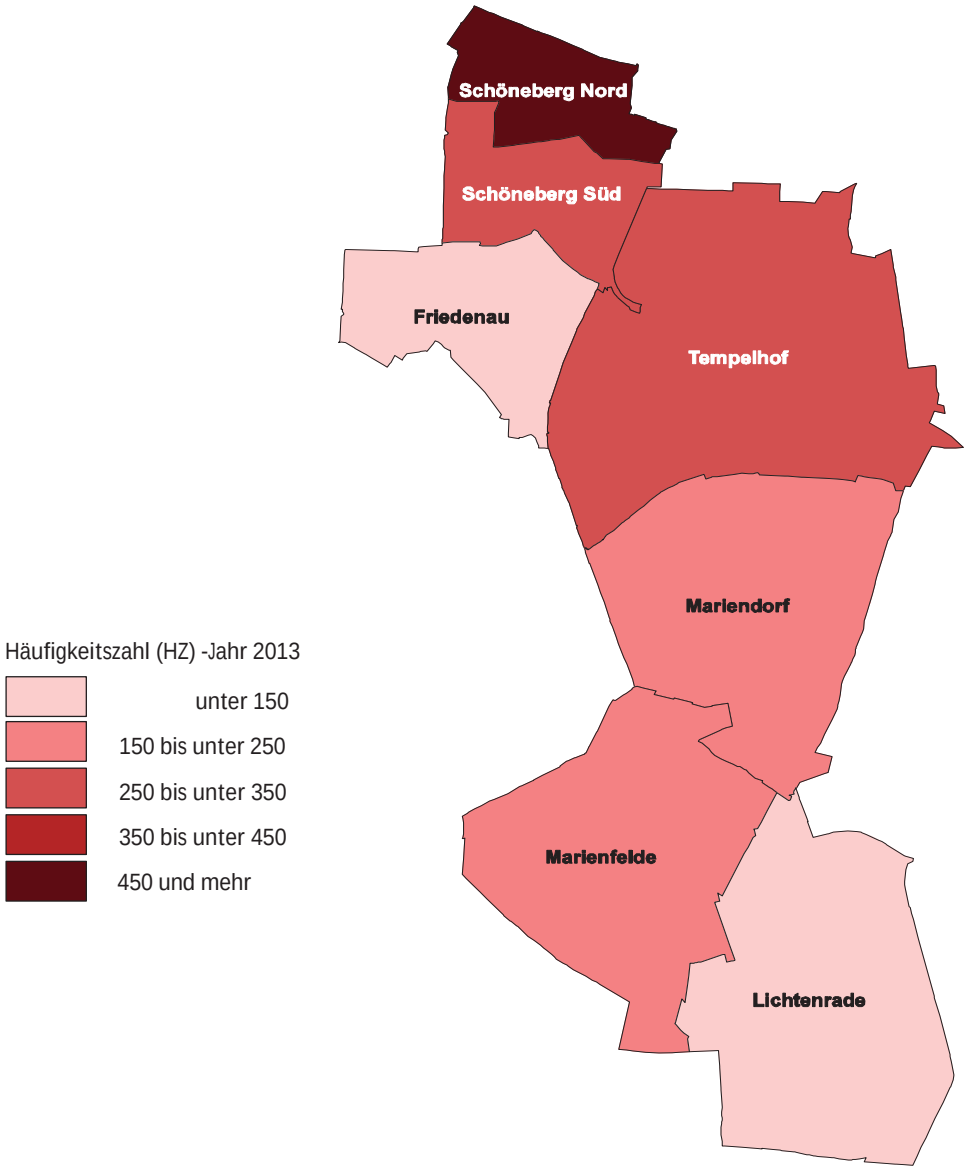

Schwere und gefährliche Körperverletzung (PKS-Schlüssel 222000)

Bezirksregion	Jahr 2012		Jahr 2013		Zu-/Abnahme			
	erfasste Fälle	HZ	erfasste Fälle	HZ	Fälle absolut	Fälle in %	HZ absolut	HZ in %
Schöneberg Nord.....	215	456	237	505	22	10,2	49	10,7
Schöneberg Süd.....	119	250	149	312	30	25,2	62	24,8
Friedenau.....	66	150	43	97	- 23	x	- 53	(- 35,3)
Tempelhof.....	129	219	155	258	26	20,2	39	17,8
Mariendorf.....	79	159	90	180	11	x	21	(13,2)
Marienfelde.....	41	135	56	183	15	x	48	(35,6)
Lichtenrade.....	60	121	64	129	4	x	8	(6,6)
nicht zuzuordnen.....	26		14					

Bezirk Berlin Neukölln

Schwere und gefährliche Körperverletzung (Häufigkeitszahl)

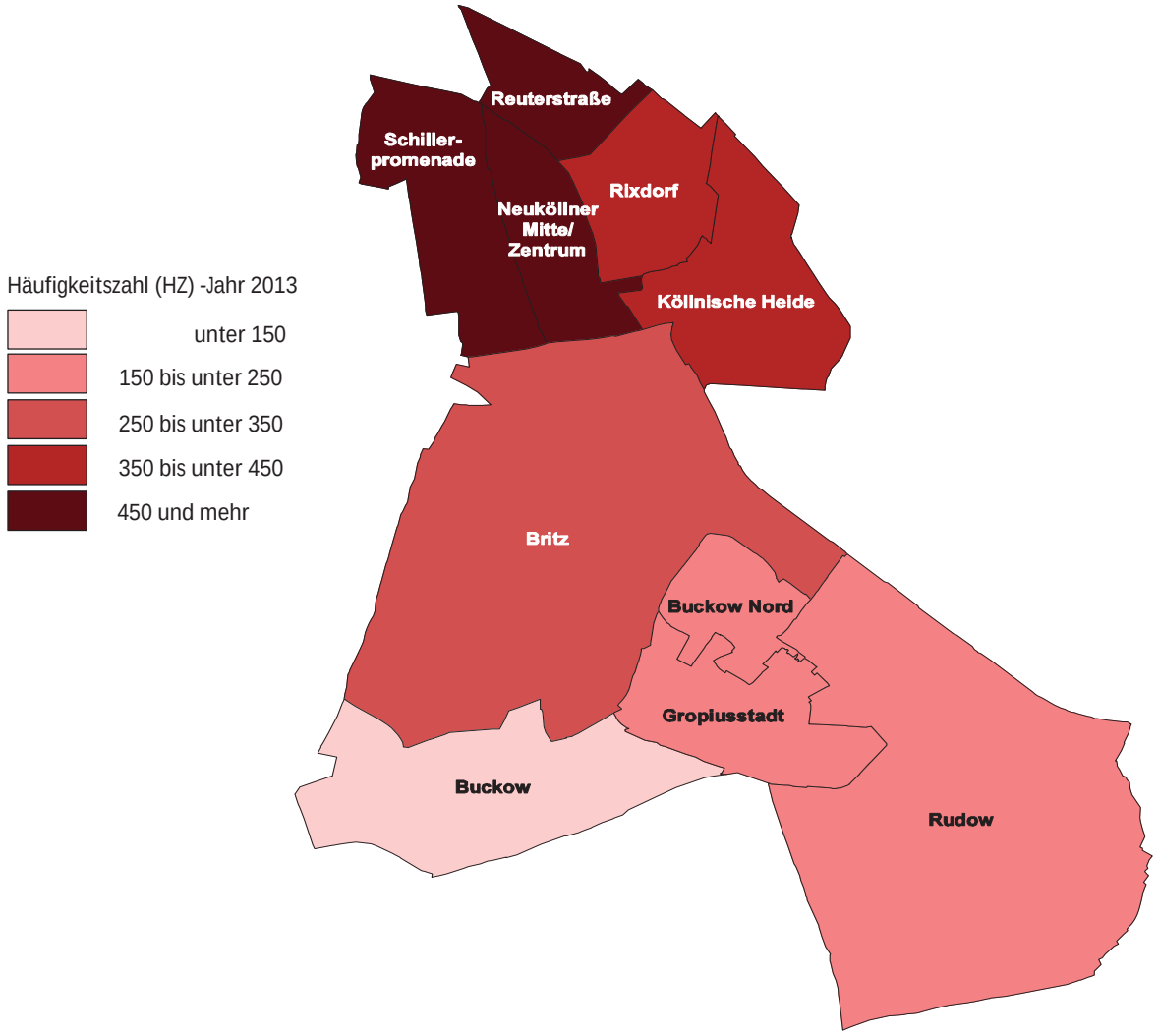

Schwere und gefährliche Körperverletzung (PKS-Schlüssel 222000)

Bezirksregion	Jahr 2012		Jahr 2013		Zu-/Abnahme			
	erfasste Fälle	HZ	erfasste Fälle	HZ	Fälle absolut	Fälle in %	HZ absolut	HZ in %
Schillerpromenade	213	689	218	691	5	2,3	2	0,3
Neuköllner Mitte/Zentrum	290	786	237	628	- 53	- 18,3	- 158	- 20,1
Reuterstraße	181	466	182	458	1	0,6	- 8	- 1,7
Rixdorf	198	509	168	425	- 30	- 15,2	- 84	- 16,5
Köllnische Heide	71	482	65	432	- 6	x	- 50	(- 10,4)
Britz	105	259	113	275	8	7,6	16	6,2
Buckow	58	210	38	136	- 20	x	- 74	(- 35,2)
Gropiusstadt	72	200	65	179	- 7	x	- 21	(- 10,5)
Buckow Nord	11	118	19	203	8	x	85	(72,0)
Rudow	50	119	69	164	19	x	45	(37,8)
nicht zuzuordnen	23		17					

Bezirk Berlin Treptow-Köpenick

Schwere und gefährliche Körperverletzung (Häufigkeitszahl)

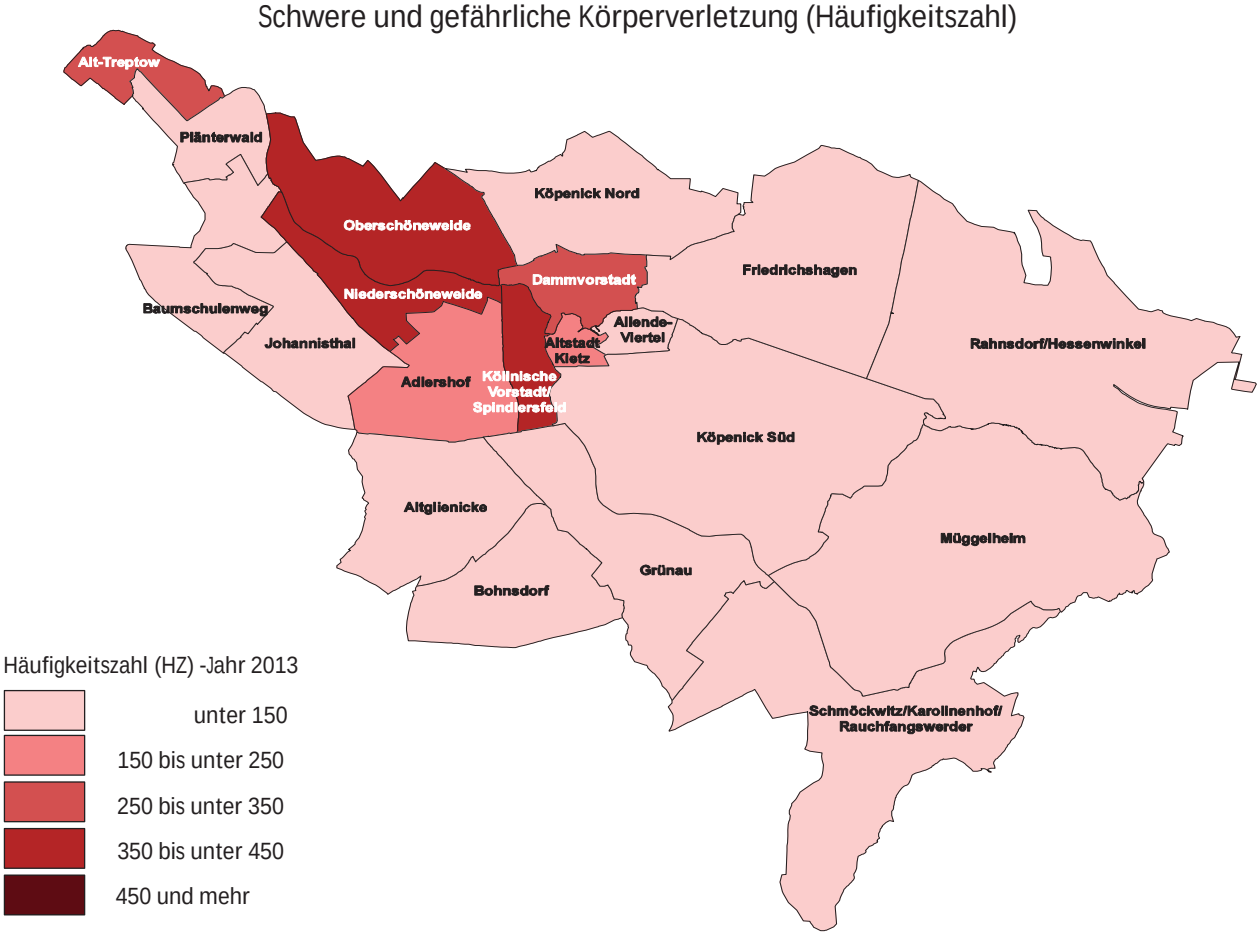

Schwere und gefährliche Körperverletzung (PKS-Schlüssel 222000)

Bezirksregion	Jahr 2012		Jahr 2013		Zu-/Abnahme			
	erfasste Fälle	HZ	erfasste Fälle	HZ	Fälle absolut	Fälle in %	HZ absolut	HZ in %
Alt-Treptow	37	339	30	270	- 7	x	- 69	(- 20,4)
Plänterwald	18	167	16	148	- 2	x	- 19	(- 11,4)
Baumschulenweg	27	157	20	115	- 7	x	- 42	(- 26,8)
Johannisthal	27	147	16	87	- 11	x	- 60	(- 40,8)
Oberschöneweide	58	303	81	411	23	x	108	(35,6)
Niederschöneweide	31	297	40	376	9	x	79	(26,6)
Adlershof	29	188	34	218	5	x	30	(16,0)
Kölln. Vorstadt/Spindlersf.	29	295	35	350	6	x	55	(18,6)
Altglienicke	22	86	32	124	10	x	38	x
Bohnsdorf	11	92	9	75	- 2	x	- 17	x
Grünau	11	204	5	89	- 6	x	- 115	(- 56,4)
Schmöckwitz/Karolinenhof	3	74	3	74		x		x
Köpenick Süd	9	58	9	58		x		x
Allende-Viertel	6	98	2	33	- 4	x	- 65	x
Altstadt Kietz	15	218	15	216		x	- 2	(- 0,9)
Müggelheim		-	1	15	1	x	15	x
Friedrichshagen	11	63	16	92	5	x	29	x
Rahnsdorf/Hessenwinkel	7	78	4	45	- 3	x	- 33	x
Dammvorstadt	30	318	28	294	- 2	x	- 24	(- 7,5)
Köpenick Nord	9	73	14	114	5	x	41	x
nicht zuzuordnen	36		25					

Bezirk Berlin Marzahn-Hellersdorf

Schwere und gefährliche Körperverletzung (Häufigkeitszahl)

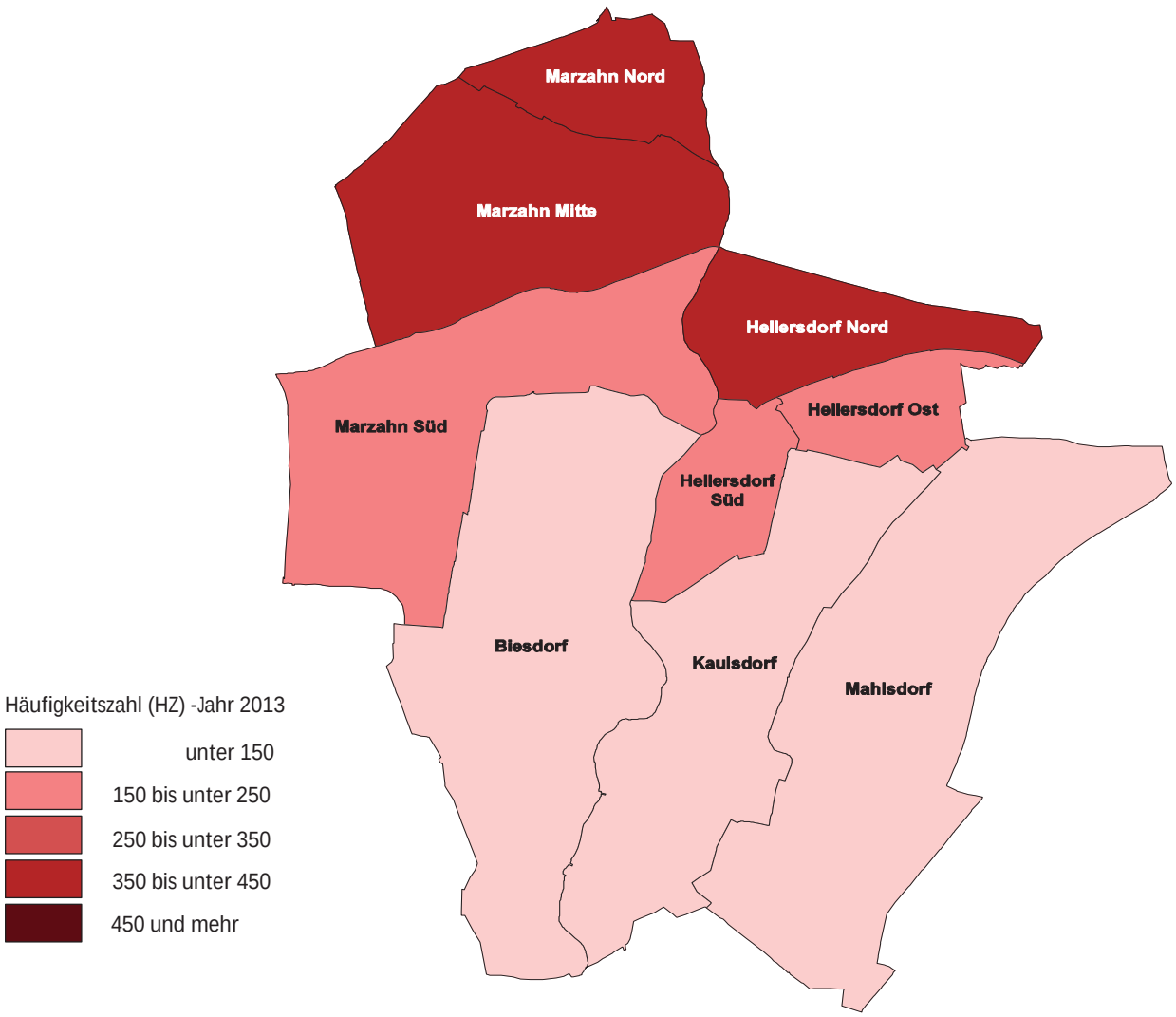

Schwere und gefährliche Körperverletzung (PKS-Schlüssel 222000)

Bezirksregion	Jahr 2012		Jahr 2013		Zu-/Abnahme			
	erfasste Fälle	HZ	erfasste Fälle	HZ	Fälle		HZ	
					absolut	in %	absolut	in %
Marzahn Nord	89	393	87	379	- 2	x	- 14	(- 3,6)
Marzahn Mitte	131	290	165	362	34	26,0	72	24,8
Marzahn Süd	61	169	68	186	7	x	17	(10,1)
Hellersdorf Nord	143	436	141	423	- 2	- 1,4	- 13	- 3,0
Hellersdorf Ost	70	379	38	201	- 32	x	- 178	(- 47,0)
Hellersdorf Süd	44	181	48	197	4	x	16	(8,8)
Biesdorf	31	123	23	90	- 8	x	- 33	(- 26,8)
Kaulsdorf	15	80	13	70	- 2	x	- 10	x
Mahlsdorf	20	74	14	52	- 6	x	- 22	x
nicht zuzuordnen	21		18					

Bezirk Berlin Lichtenberg

Schwere und gefährliche Körperverletzung (Häufigkeitszahl)

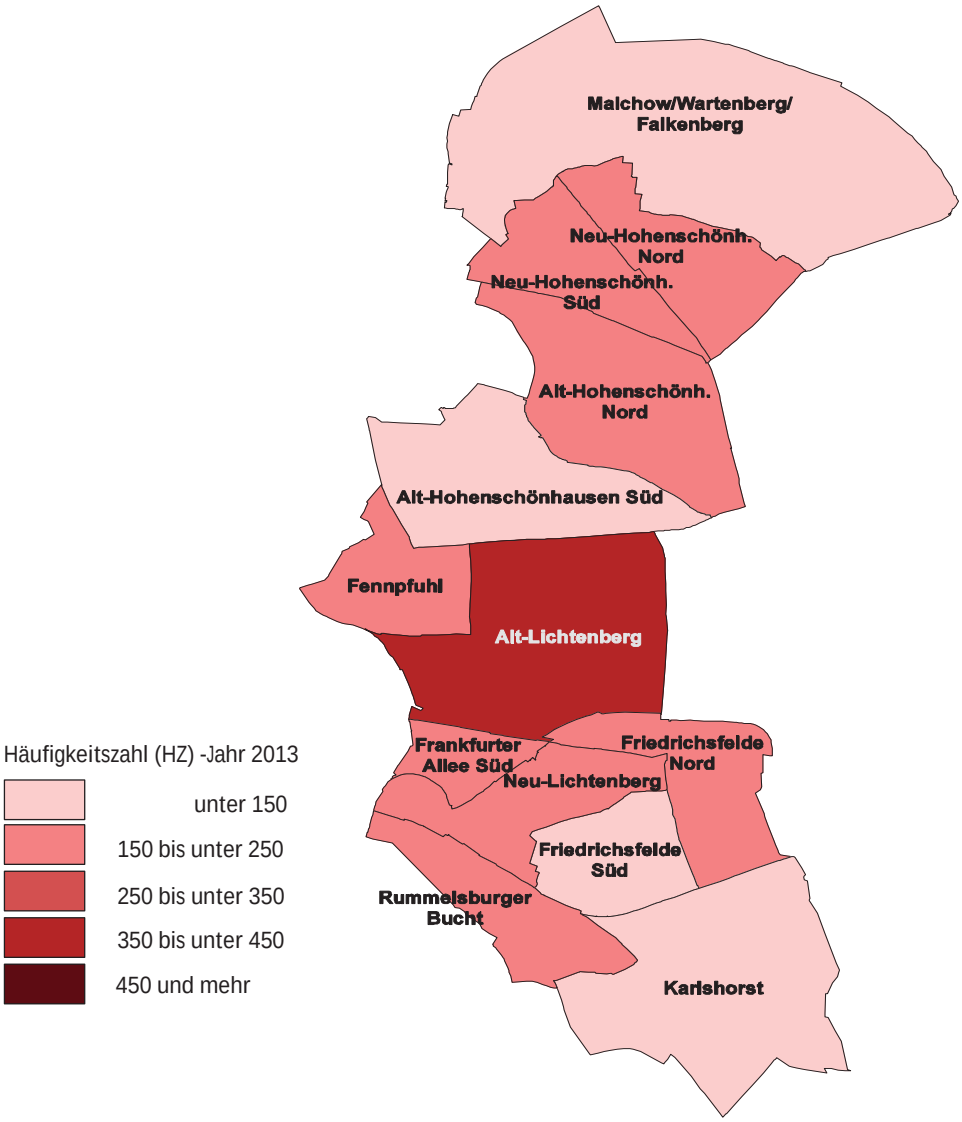

Schwere und gefährliche Körperverletzung (PKS-Schlüssel 222000)

Bezirksregion	Jahr 2012		Jahr 2013		Zu-/Abnahme			
	erfasste Fälle	HZ	erfasste Fälle	HZ	Fälle absolut	Fälle in %	HZ absolut	HZ in %
Malchow/Warten-/Falkenberg.....	4	95	3	71	- 1	x	- 24	x
Neu-Hohenschönhausen Nord.....	53	193	59	213	6	x	20	(10,4)
Neu-Hohenschönhausen Süd.....	84	325	49	190	- 35	x	- 135	(- 41,5)
Alt-Hohenschönhausen Nord.....	34	252	23	171	- 11	x	- 81	(- 32,1)
Alt-Hohenschönhausen Süd.....	48	163	37	126	- 11	x	- 37	(- 22,7)
Fennpfuhl.....	77	243	49	153	- 28	x	- 90	(- 37,0)
Alt-Lichtenberg.....	81	337	99	397	18	x	60	(17,8)
Frankfurter Allee Süd.....	18	186	15	150	- 3	x	- 36	(- 19,4)
Neu-Lichtenberg.....	68	232	48	160	- 20	x	- 72	(- 31,0)
Friedrichsfelde Nord.....	43	323	33	244	- 10	x	- 79	(- 24,5)
Friedrichsfelde Süd.....	34	141	32	130	- 2	x	- 11	(- 7,8)
Rummelsburger Bucht.....	6	184	7	211	1	x	27	(14,7)
Karlshorst.....	18	80	22	94	4	x	14	x
nicht zuzuordnen.....	18		24					

Bezirk Berlin Reinickendorf

Schwere und gefährliche Körperverletzung (Häufigkeitszahl)

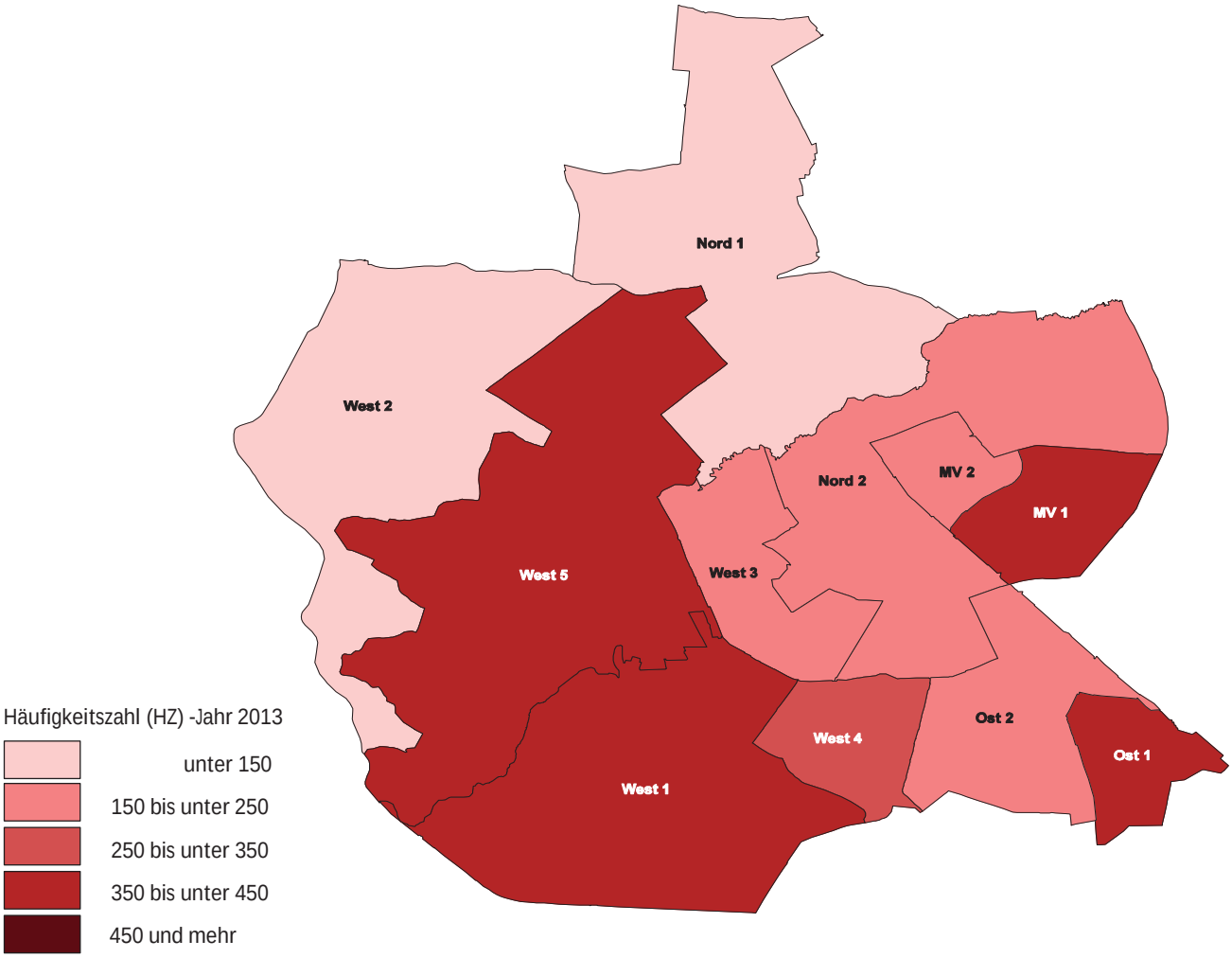

Schwere und gefährliche Körperverletzung (PKS-Schlüssel 222000)

Bezirksregion	Jahr 2012		Jahr 2013		Zu-/Abnahme			
	erfasste Fälle	HZ	erfasste Fälle	HZ	Fälle absolut	Fälle in %	HZ absolut	HZ in %
Ost 1	101	394	94	362	- 7	- 6,9	- 32	- 8,1
Ost 2	63	247	63	244		x	- 3	(- 1,2)
West 1	73	502	52	359	- 21	x	- 143	(- 28,5)
West 4	96	384	80	315	- 16	x	- 69	(- 18,0)
West 5	67	656	38	369	- 29	x	- 287	(- 43,8)
West 2	10	42	15	63	5	x	21	x
Nord 1	30	92	23	70	- 7	x	- 22	x
Nord 2	79	271	61	205	- 18	x	- 66	(- 24,4)
MV 1	126	356	135	371	9	7,1	15	4,2
MV 2	21	256	21	247		x	- 9	(- 3,5)
West 3	37	232	27	169	- 10	x	- 63	(- 27,2)
nicht zuzuordnen	10		7					

Berlin - Nachstellung, Nötigung, Freiheitsberaubung, Bedrohung (Häufigkeitszahl)

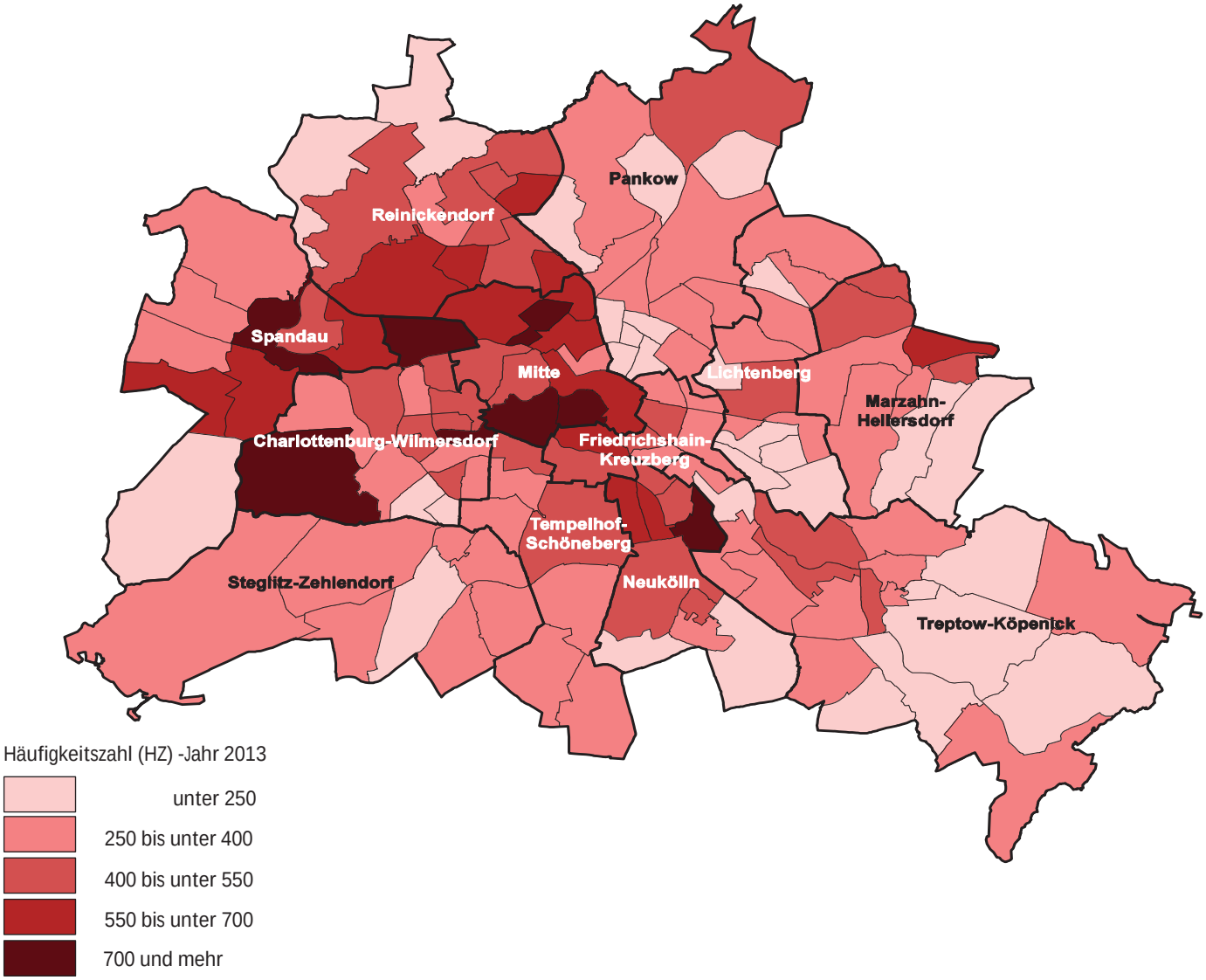

Nachstellung, Nötigung, Freiheitsberaubung, Bedrohung (PKS-Schlüssel 232000)

Bezirk	Jahr 2012		Jahr 2013		Zu-/Abnahme			
	erfasste Fälle	HZ	erfasste Fälle	HZ	Fälle absolut	Fälle in %	HZ absolut	HZ in %
Mitte	2 242	668	2 233	650	- 9	- 0,4	- 18	- 2,7
Friedrichshain-Kreuzberg	1 153	432	1 168	431	15	1,3	- 1	- 0,2
Pankow	963	262	1 051	281	88	9,1	19	7,3
Charlottenburg-Wilmersdorf	1 427	450	1 507	470	80	5,6	20	4,4
Spandau	1 090	492	1 078	480	- 12	- 1,1	- 12	- 2,4
Steglitz-Zehlendorf	849	289	872	294	23	2,7	5	1,7
Tempelhof-Schöneberg	1 301	398	1 278	388	- 23	- 1,8	- 10	- 2,5
Neukölln	1 594	505	1 498	468	- 96	- 6,0	- 37	- 7,3
Treptow-Köpenick	668	276	775	317	107	16,0	41	14,9
Marzahn-Hellersdorf	929	371	972	384	43	4,6	13	3,5
Lichtenberg	789	305	753	287	- 36	- 4,6	- 18	- 5,9
Reinickendorf	1 191	484	1 148	461	- 43	- 3,6	- 23	- 4,8
Berlin, nicht zuzuordnen	517		583					
Berlin -Gesamt-	**14 713**	**436**	**14 916**	**438**	**203**	**1,4**	**2**	**0,4**

Bezirk Berlin Mitte

Nachstellung, Nötigung, Freiheitsberaubung, Bedrohung (Häufigkeitszahl)

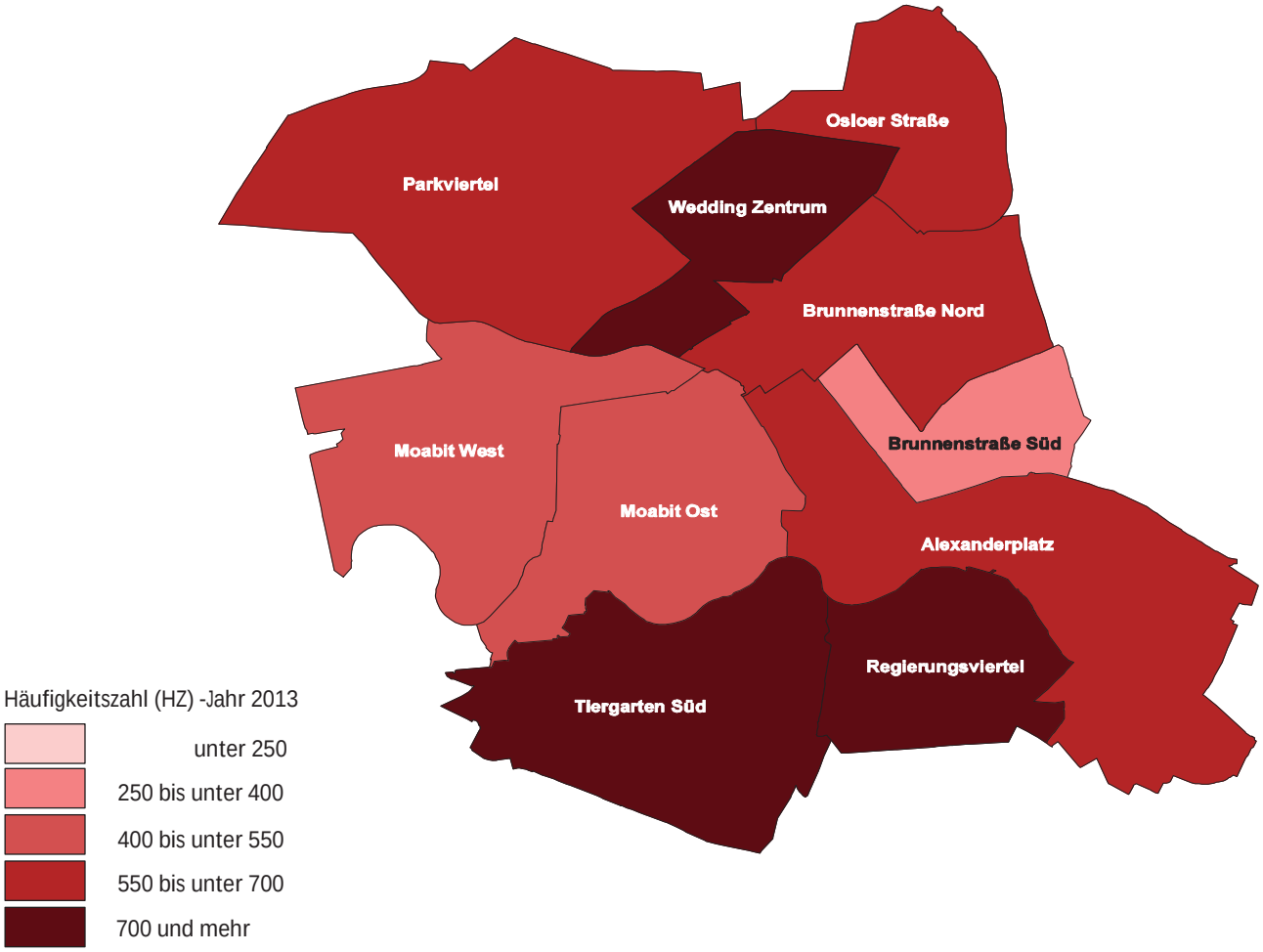

Nachstellung, Nötigung, Freiheitsberaubung, Bedrohung (PKS-Schlüssel 232000)

Bezirksregion	Jahr 2012		Jahr 2013		Zu-/Abnahme			
	erfasste Fälle	HZ	erfasste Fälle	HZ	Fälle		HZ	
					absolut	in %	absolut	in %
Tiergarten Süd	118	937	124	953	6	5,1	16	1,7
Regierungsviertel	142	1 549	128	1 377	- 14	- 9,9	- 172	- 11,1
Alexanderplatz	304	644	333	692	29	9,5	48	7,5
Brunnenstraße Süd	66	258	68	256	2	x	- 2	(-0,8)
Moabit West	199	475	231	540	32	16,1	65	13,7
Moabit Ost	204	586	181	513	- 23	- 11,3	- 73	- 12,5
Osloer Straße	267	762	253	699	- 14	- 5,2	- 63	- 8,3
Brunnenstraße Nord	191	541	200	558	9	4,7	17	3,1
Parkviertel	318	767	269	635	- 49	- 15,4	- 132	- 17,2
Wedding Zentrum	384	731	382	706	- 2	- 0,5	- 25	- 3,4
nicht zuzuordnen	49	-	64	-				

Bezirk Berlin Friedrichshain-Kreuzberg

Nachstellung, Nötigung, Freiheitsberaubung, Bedrohung (Häufigkeitszahl)

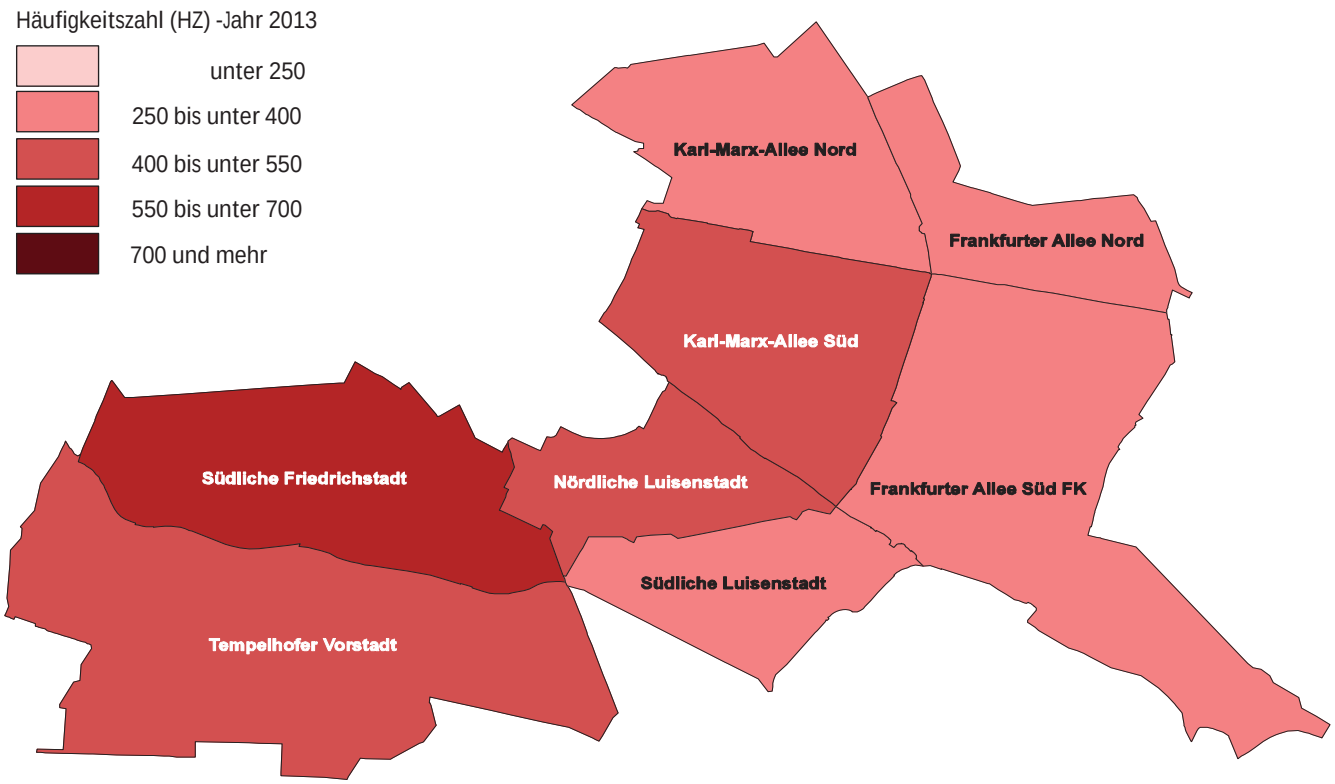

Nachstellung, Nötigung, Freiheitsberaubung, Bedrohung (PKS-Schlüssel 232000)

Bezirksregion	Jahr 2012		Jahr 2013		Zu-/Abnahme			
	erfasste Fälle	HZ	erfasste Fälle	HZ	Fälle		HZ	
					absolut	in %	absolut	in %
Südliche Friedrichstadt.....	263	675	243	615	- 20	- 7,6	- 60	- 8,9
Tempelhofer Vorstadt.....	241	396	282	455	41	17,0	59	14,9
Nördliche Luisenstadt.....	126	564	115	510	- 11	- 8,7	- 54	- 9,6
Südliche Luisenstadt.....	101	387	90	340	- 11	- 10,9	- 47	- 12,1
Karl-Marx-Allee Nord.....	55	247	66	294	11	x	47	(19,0)
Karl-Marx-Allee Süd.....	105	458	107	457	2	1,9	- 1	- 0,2
Frankfurter Allee Nord.....	80	295	77	279	- 3	x	- 16	(- 5,4)
Frankfurter Allee Süd FK.....	159	344	156	330	- 3	- 1,9	- 14	- 4,1
nicht zuzuordnen.....	23		32					

Bezirk Berlin Pankow

Nachstellung, Nötigung, Freiheitsberaubung, Bedrohung (Häufigkeitszahl)

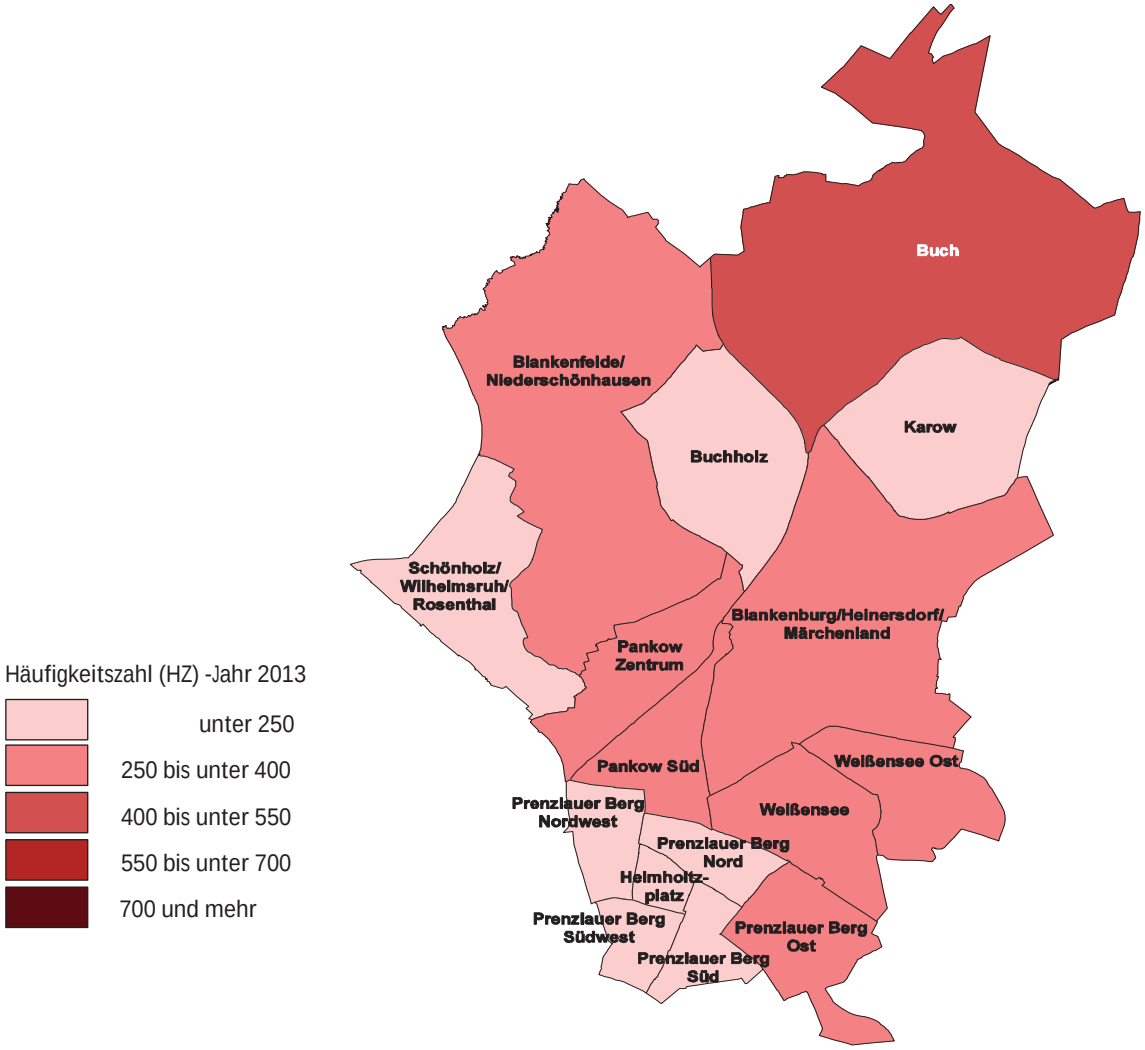

Nachstellung, Nötigung, Freiheitsberaubung, Bedrohung (PKS-Schlüssel 232000)

Bezirksregion	Jahr 2012		Jahr 2013		Zu-/Abnahme			
	erfasste Fälle	HZ	erfasste Fälle	HZ	Fälle absolut	Fälle in %	HZ absolut	HZ in %
Buch	48	368	66	487	18	x	119	(32,3)
Blankenfelde/Niederschönhausen	54	213	80	308	26	x	95	(44,6)
Buchholz	38	226	36	212	- 2	x	- 14	(- 6,2)
Karow	32	171	40	215	8	x	44	(25,7)
Blankenburg/Heinersdorf	21	149	38	269	17	x	120	(80,5)
Pankow Süd	67	210	87	268	20	x	58	(27,6)
Schönholz/Wilhelmsruh/Rosenthal	26	152	38	221	12	x	69	(45,4)
Pankow Zentrum	83	256	104	312	21	x	56	(21,9)
Weißensee	99	301	127	378	28	x	77	(25,6)
Weißensee Ost	50	333	47	311	- 3	x	- 22	(- 6,6)
Prenzlauer Berg Nordwest	83	351	59	243	- 24	x	- 108	(- 30,8)
Prenzlauer Berg Nord	60	232	65	249	5	x	17	(7,3)
Helmholtzplatz	52	245	44	203	- 8	x	- 42	(- 17,1)
Prenzlauer Berg Ost	79	325	72	290	- 7	x	- 35	(- 10,8)
Prenzlauer Berg Südwest	71	293	56	226	- 15	x	- 67	(- 22,9)
Prenzlauer Berg Süd	81	263	76	244	- 5	x	- 19	(- 7,2)
nicht zuzuordnen	19		16					

Bezirk Berlin Charlottenburg-Wilmersdorf

Nachstellung, Nötigung, Freiheitsberaubung, Bedrohung (Häufigkeitszahl)

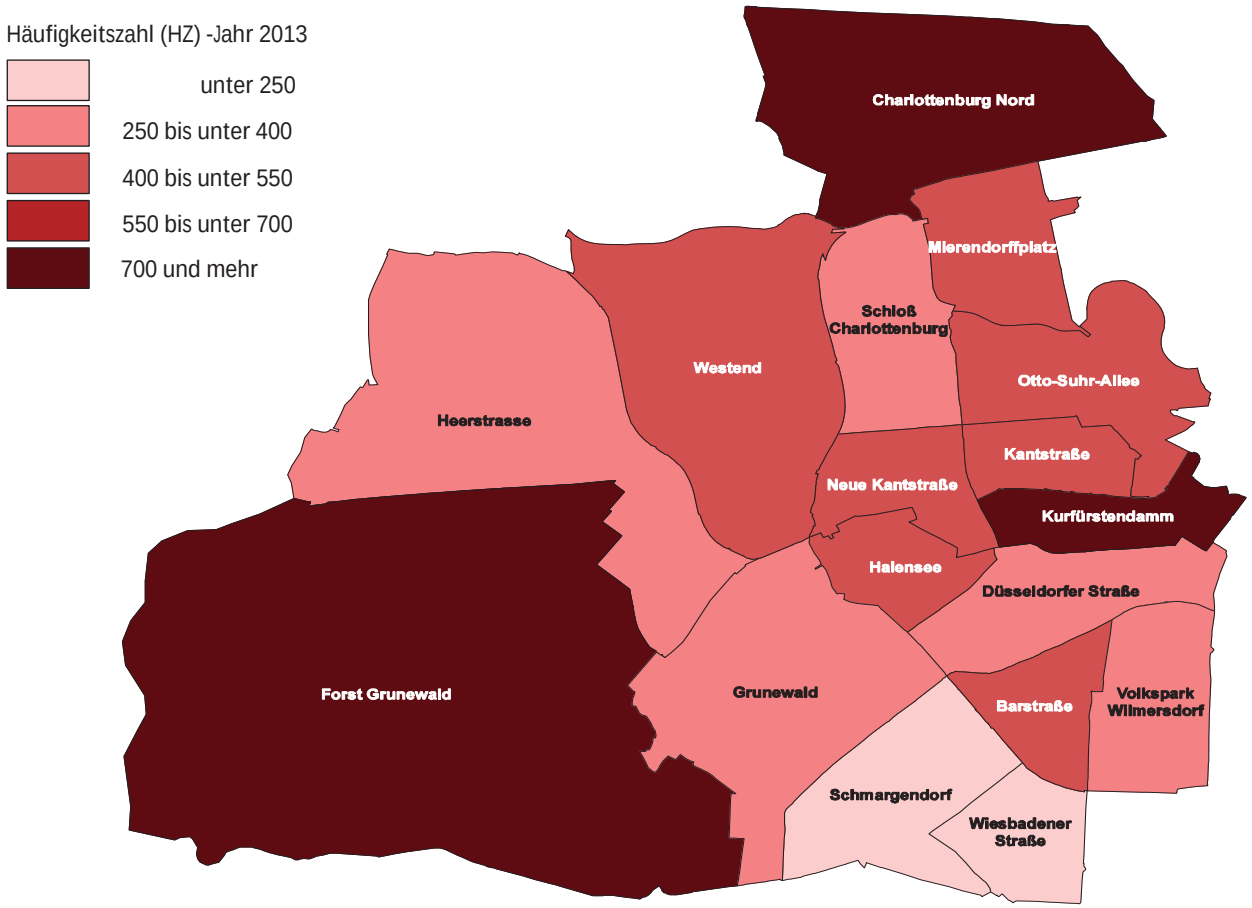

Nachstellung, Nötigung, Freiheitsberaubung, Bedrohung (PKS-Schlüssel 232000)

Bezirksregion	Jahr 2012		Jahr 2013		Zu-/Abnahme			
	erfasste Fälle	HZ	erfasste Fälle	HZ	Fälle absolut	Fälle in %	HZ absolut	HZ in %
Charlottenburg Nord.....	129	713	154	834	25	19,4	121	17,0
Heerstraße.....	36	288	45	357	9	x	69	(24,0)
Westend.....	117	447	116	435	- 1	- 0,9	- 12	- 2,7
Schloß Charlottenburg.....	90	389	92	393	2	x	4	(1,0)
Mierendorffplatz.....	61	429	70	480	9	x	51	(11,9)
Otto-Suhr-Allee.....	128	502	127	493	- 1	- 0,8	- 9	- 1,8
Neue Kantstraße.....	86	375	108	466	22	x	91	(24,3)
Kantstraße.....	112	547	98	473	- 14	- 12,5	- 74	- 13,5
Kurfürstendamm.....	159	1 092	183	1 255	24	15,1	163	14,9
Halensee.....	62	437	71	492	9	x	55	(12,6)
Grunewald.....	58	324	68	373	10	x	49	(15,1)
Schmargendorf.....	41	297	33	237	- 8	x	- 60	(- 20,2)
Wiesbadener Straße.....	34	189	43	238	9	x	49	(25,9)
Düsseldorfer Straße.....	117	399	109	366	- 8	- 6,8	- 33	- 8,3
Barstraße.....	43	319	57	420	14	x	101	(31,7)
Volkspark Wilmersdorf.....	110	340	95	290	- 15	- 13,6	- 50	- 14,7
Forst Grunewald.....	4		5		1	x		
nicht zuzuordnen.....	40		33					

Bezirk Berlin Spandau

Nachstellung, Nötigung, Freiheitsberaubung, Bedrohung (Häufigkeitszahl)

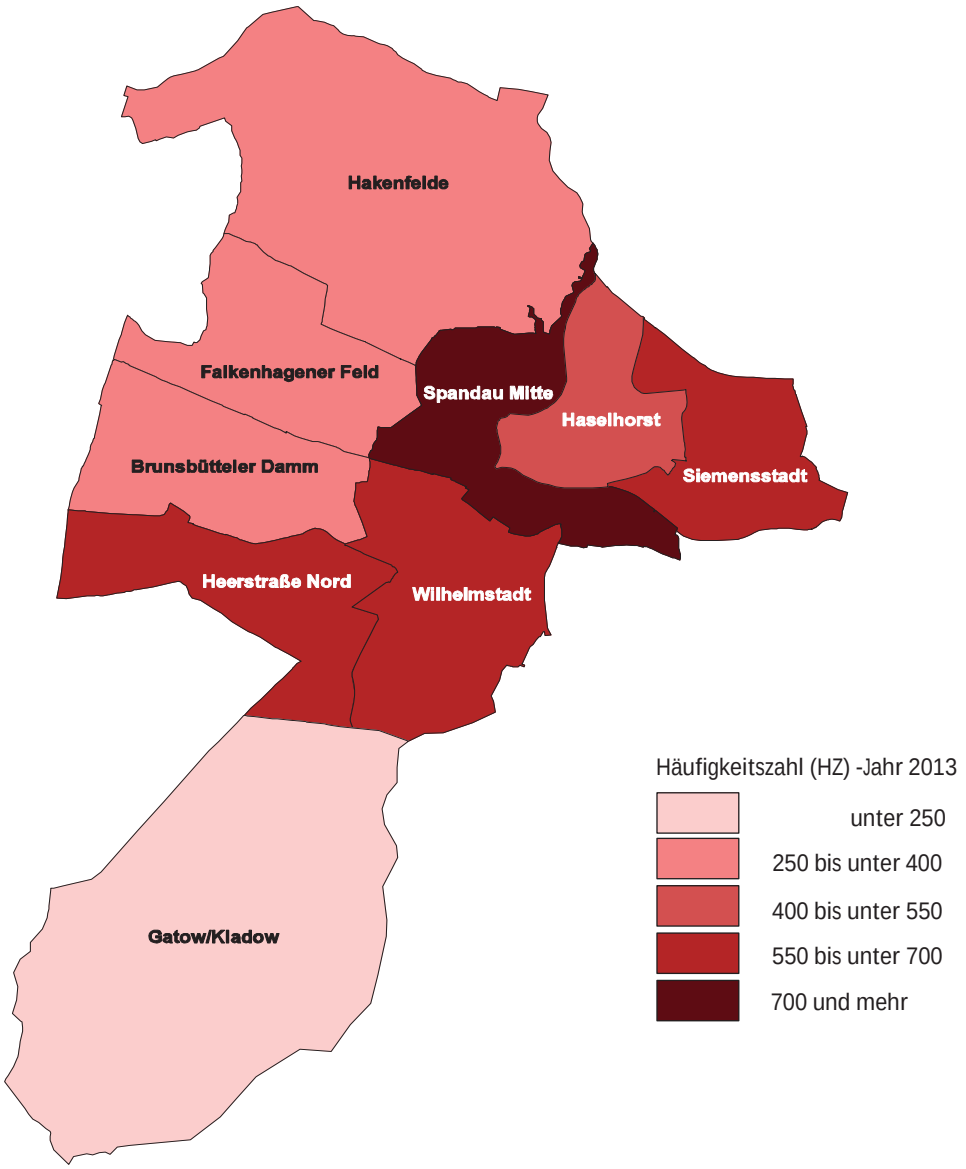

Nachstellung, Nötigung, Freiheitsberaubung, Bedrohung (PKS-Schlüssel 232000)

Bezirksregion	Jahr 2012		Jahr 2013		Zu-/Abnahme			
	erfasste Fälle	HZ	erfasste Fälle	HZ	Fälle absolut	Fälle in %	HZ absolut	HZ in %
Hakenfelde.....	86	379	76	335	- 10	x	- 44	(- 11,6)
Falkenhagener Feld.....	181	464	150	382	- 31	- 17,1	- 82	- 17,7
Spandau Mitte.....	258	785	243	721	- 15	- 5,8	- 64	- 8,2
Brunsbütteler Damm.....	61	264	59	255	- 2	x	- 9	(- 3,4)
Heerstraße Nord.....	157	588	159	594	2	1,3	6	1,0
Wilhelmstadt.....	177	522	217	632	40	22,6	110	21,1
Haselhorst.....	70	508	64	443	- 6	x	- 65	(- 12,8)
Siemensstadt.....	63	542	67	559	4	x	17	(3,1)
Gatow/Kladow.....	25	141	32	176	7	x	35	(24,8)
nicht zuzuordnen.....	12		11					

Bezirk Berlin Steglitz-Zehlendorf

Nachstellung, Nötigung, Freiheitsberaubung, Bedrohung (Häufigkeitszahl)

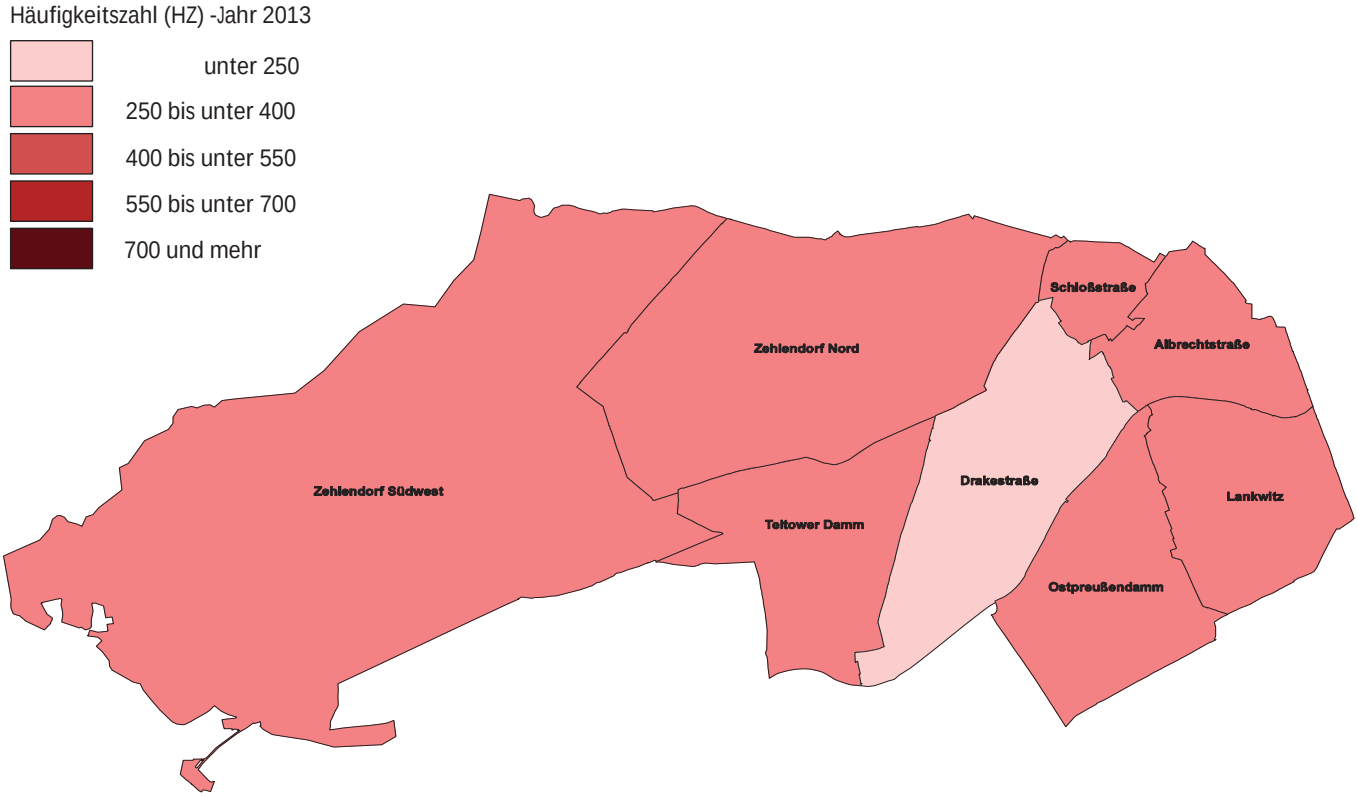

Nachstellung, Nötigung, Freiheitsberaubung, Bedrohung (PKS-Schlüssel 232000)

Bezirksregion	Jahr 2012		Jahr 2013		Zu-/Abnahme			
	erfasste Fälle	HZ	erfasste Fälle	HZ	Fälle absolut	Fälle in %	HZ absolut	HZ in %
Schloßstraße	51	238	71	328	20	x	90	(37,8)
Albrechtstraße	161	314	145	280	- 16	- 9,9	- 34	- 10,8
Lankwitz	161	389	138	330	- 23	- 14,3	- 59	- 15,2
Ostpreußendamm	68	196	97	277	29	x	81	(41,3)
Teltower Damm	86	263	92	281	6	x	18	(6,8)
Drakestraße	106	232	108	232	2	1,9		-
Zehlendorf Südwest	83	325	77	301	- 6	x	- 24	(- 7,4)
Zehlendorf Nord	120	289	118	284	- 2	- 1,7	- 5	- 1,7
nicht zuzuordnen	13		26					

Bezirk Berlin Tempelhof-Schöneberg

Nachstellung, Nötigung, Freiheitsberaubung, Bedrohung (Häufigkeitszahl)

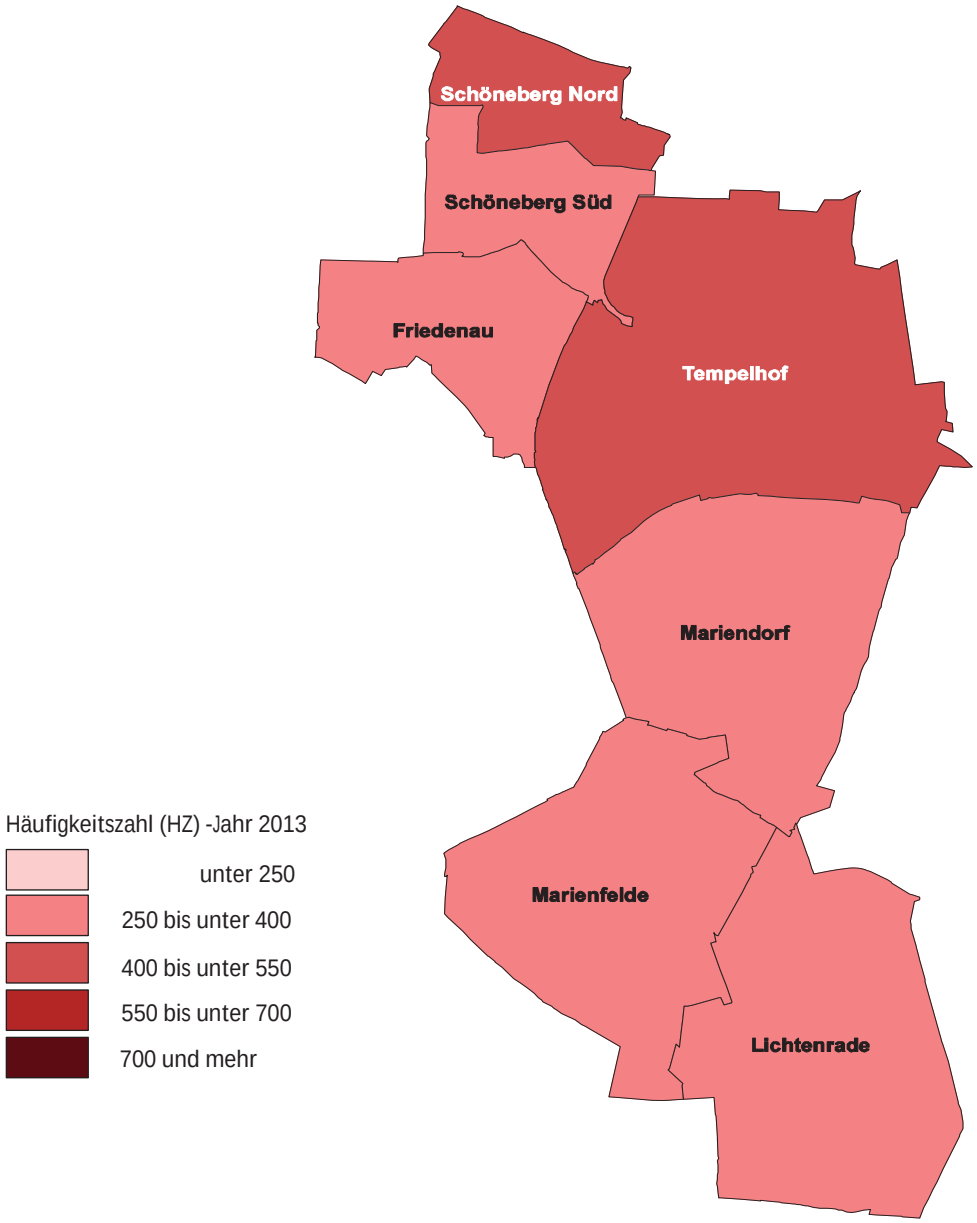

Nachstellung, Nötigung, Freiheitsberaubung, Bedrohung (PKS-Schlüssel 232000)

Bezirksregion	Jahr 2012		Jahr 2013		Zu-/Abnahme			
	erfasste Fälle	HZ	erfasste Fälle	HZ	Fälle absolut	Fälle in %	HZ absolut	HZ in %
Schöneberg Nord.....	239	507	243	518	4	1,7	11	2,2
Schöneberg Süd.....	162	341	177	371	15	9,3	30	8,8
Friedenau.....	165	375	115	259	- 50	- 30,3	- 116	- 30,9
Tempelhof.....	351	595	299	498	- 52	- 14,8	- 97	- 16,3
Mariendorf.....	150	301	178	356	28	18,7	55	18,3
Marienfelde.....	98	322	109	357	11	x	35	(10,9)
Lichtenrade.....	114	231	135	272	21	18,4	41	17,7
nicht zuzuordnen.....	22		22					

Bezirk Berlin Neukölln

Nachstellung, Nötigung, Freiheitsberaubung, Bedrohung (Häufigkeitszahl)

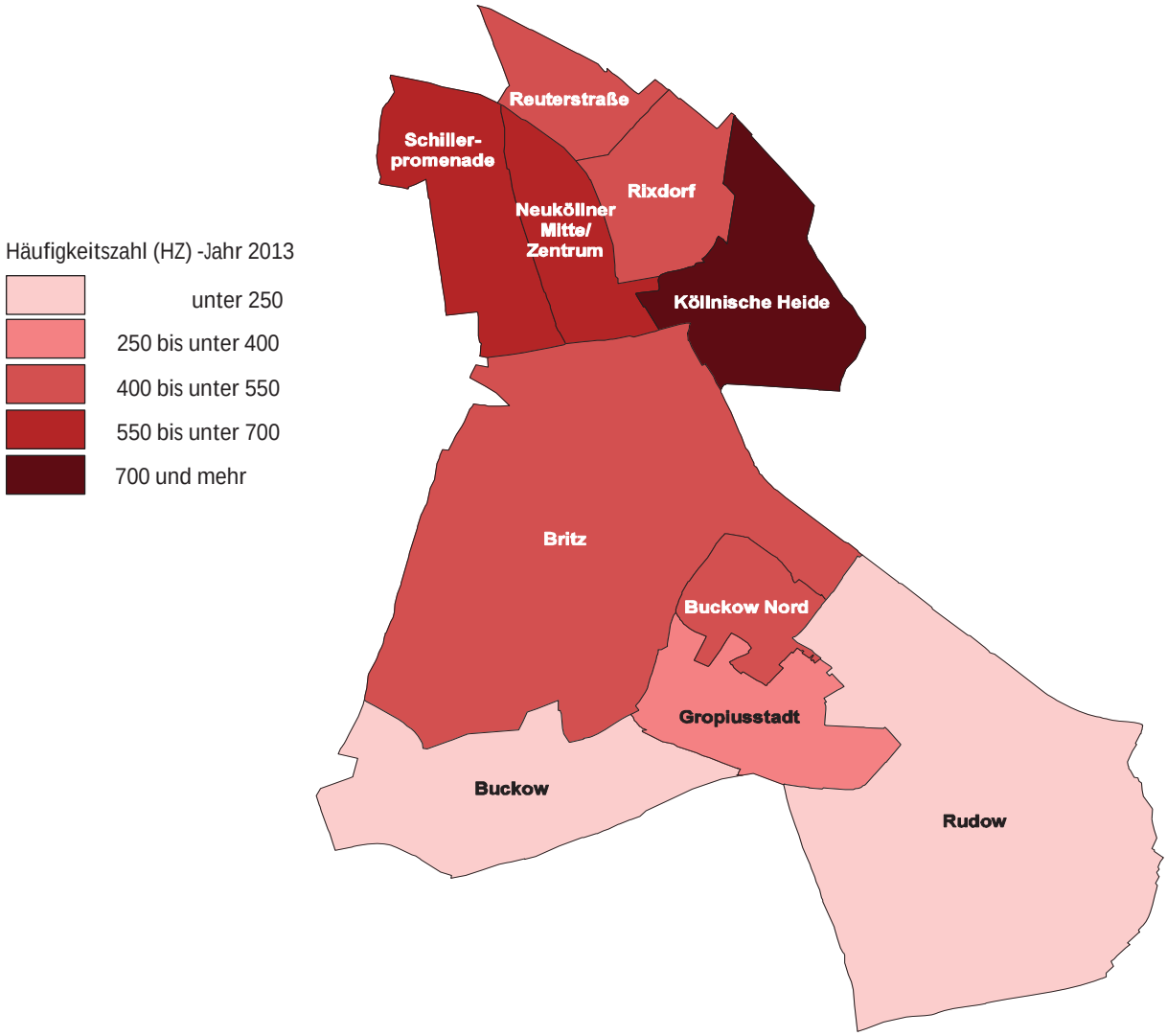

Nachstellung, Nötigung, Freiheitsberaubung, Bedrohung (PKS-Schlüssel 232000)

Bezirksregion	Jahr 2012		Jahr 2013		Zu-/Abnahme			
	erfasste Fälle	HZ	erfasste Fälle	HZ	Fälle absolut	Fälle in %	HZ absolut	HZ in %
Schillerpromenade	252	815	208	659	- 44	- 17,5	- 156	- 19,1
Neuköllner Mitte/Zentrum	288	781	248	657	- 40	- 13,9	- 124	- 15,9
Reuterstraße	163	420	173	435	10	6,1	15	3,6
Rixdorf	221	569	201	509	- 20	- 9,0	- 60	- 10,5
Köllnische Heide	121	821	132	878	11	9,1	57	6,9
Britz	168	415	199	484	31	18,5	69	16,6
Buckow	107	388	69	248	- 38	- 35,5	- 140	- 36,1
Gropiusstadt	131	363	115	316	- 16	- 12,2	- 47	- 12,9
Buckow Nord	34	366	38	406	4	x	40	(10,9)
Rudow	90	215	104	247	14	x	32	(14,9)
nicht zuzuordnen	19		11					

Bezirk Berlin Treptow-Köpenick

Nachstellung, Nötigung, Freiheitsberaubung, Bedrohung (Häufigkeitszahl)

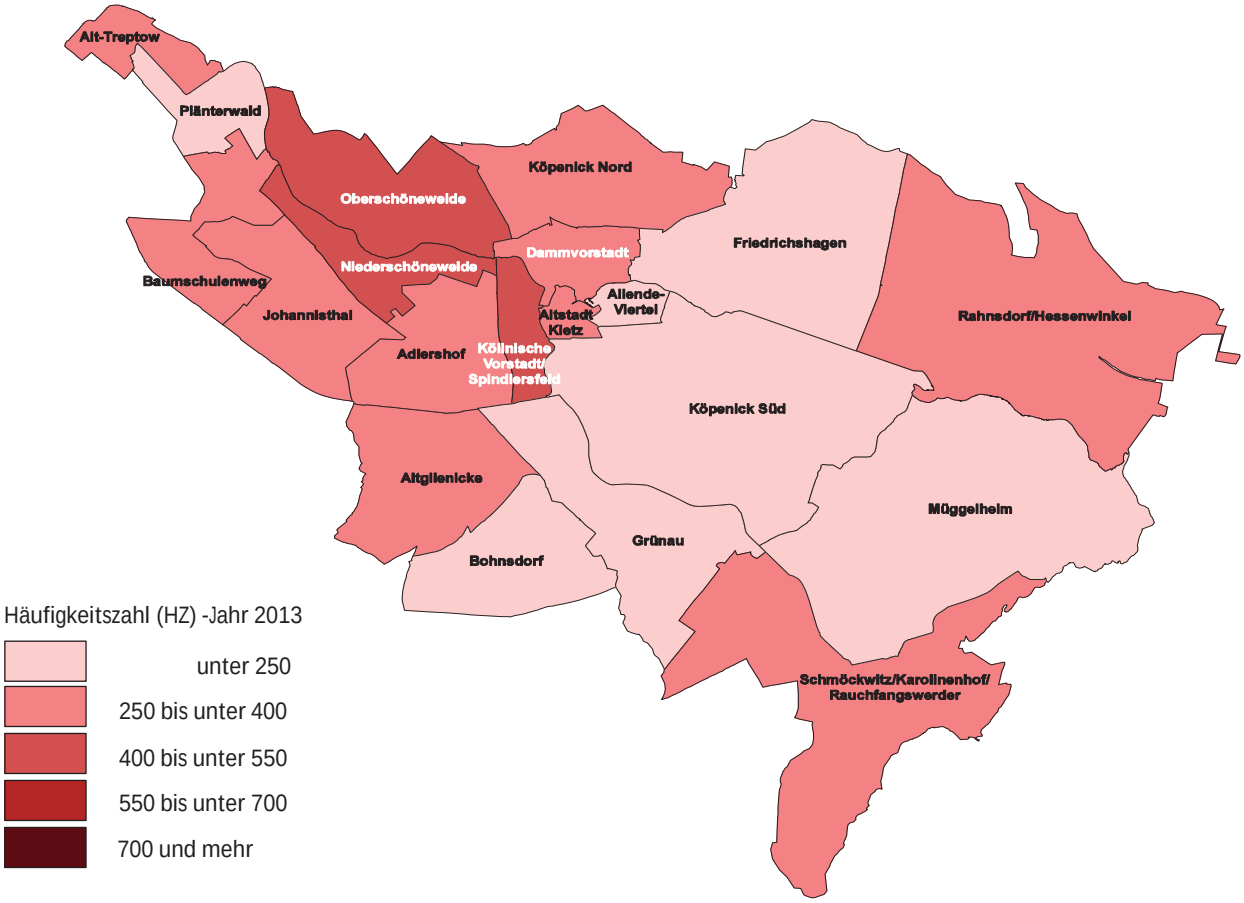

Nachstellung, Nötigung, Freiheitsberaubung, Bedrohung (PKS-Schlüssel 232000)

Bezirksregion	Jahr 2012		Jahr 2013		Zu-/Abnahme			
	erfasste Fälle	HZ	erfasste Fälle	HZ	Fälle absolut	Fälle in %	HZ absolut	HZ in %
Alt-Treptow	35	320	33	297	- 2	x	- 23	(- 7,2)
Plänterwald	21	195	25	231	4	x	36	(18,5)
Baumschulenweg	60	348	59	339	- 1	x	- 9	(- 2,6)
Johannisthal	52	284	61	331	9	x	47	(16,5)
Oberschöneweide	78	407	99	502	21	x	95	(23,3)
Niederschöneweide	48	459	44	414	- 4	x	- 45	(- 9,8)
Adlershof	48	312	57	365	9	x	53	(17,0)
Kölln. Vorstadt/Spindlersf.	30	305	41	410	11	x	105	(34,4)
Altglienicke	73	286	73	282		x	- 4	(- 1,4)
Bohnsdorf	29	244	30	249	1	x	5	(2,0)
Grünau	11	204	12	214	1	x	10	(4,9)
Schmöckwitz/Karolinenhof	3	74	12	298	9	x	224	x
Köpenick Süd	20	128	31	199	11	x	71	(55,5)
Allende-Viertel	26	426	14	229	- 12	x	- 197	(- 46,2)
Altstadt Kietz	21	306	24	346	3	x	40	(13,1)
Müggelheim	13	200	16	245	3	x	45	(22,5)
Friedrichshagen	28	160	36	206	8	x	46	(28,8)
Rahnsdorf/Hessenwinkel	8	89	23	257	15	x	168	x
Dammvorstadt	21	223	37	389	16	x	166	(74,4)
Köpenick Nord	20	163	31	253	11	x	90	(55,2)
nicht zuzuordnen	23		17					

Bezirk Berlin Marzahn-Hellersdorf

Nachstellung, Nötigung, Freiheitsberaubung, Bedrohung (Häufigkeitszahl)

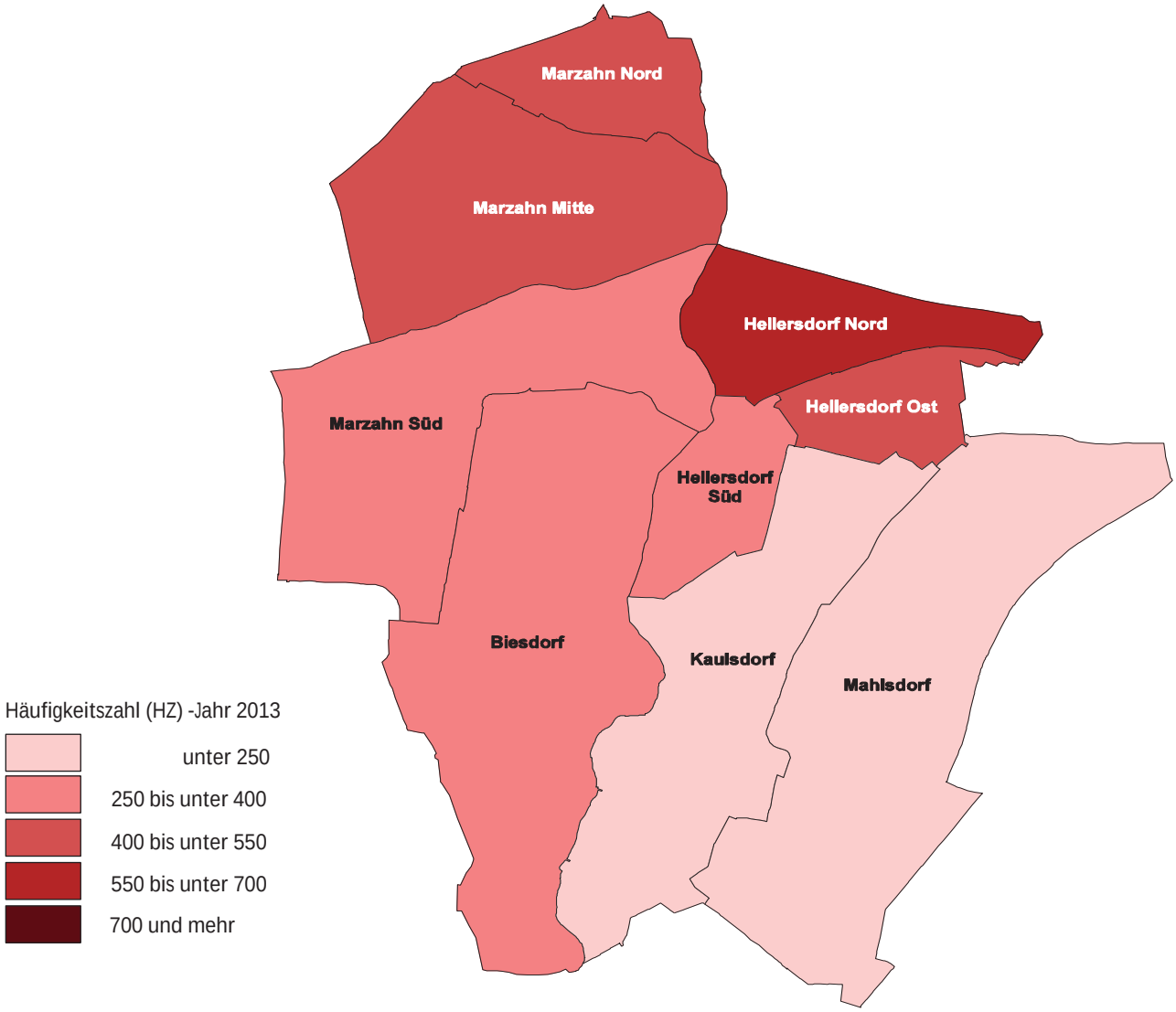

Nachstellung, Nötigung, Freiheitsberaubung, Bedrohung (PKS-Schlüssel 232000)

Bezirksregion	Jahr 2012		Jahr 2013		Zu-/Abnahme			
	erfasste Fälle	HZ	erfasste Fälle	HZ	Fälle		HZ	
					absolut	in %	absolut	in %
Marzahn Nord	104	459	115	501	11	10,6	42	9,2
Marzahn Mitte	204	451	184	403	- 20	- 9,8	- 48	- 10,6
Marzahn Süd	91	252	125	342	34	x	90	(35,7)
Hellersdorf Nord	175	534	194	583	19	10,9	49	9,2
Hellersdorf Ost	101	547	80	424	- 21	- 20,8	- 123	- 22,5
Hellersdorf Süd	95	392	86	352	- 9	x	- 40	(- 10,2)
Biesdorf	55	219	77	302	22	x	83	(37,9)
Kaulsdorf	39	209	41	220	2	x	11	(5,3)
Mahlsdorf	49	182	55	203	6	x	21	(11,5)
nicht zuzuordnen	16		15					

Bezirk Berlin Lichtenberg

Nachstellung, Nötigung, Freiheitsberaubung, Bedrohung (Häufigkeitszahl)

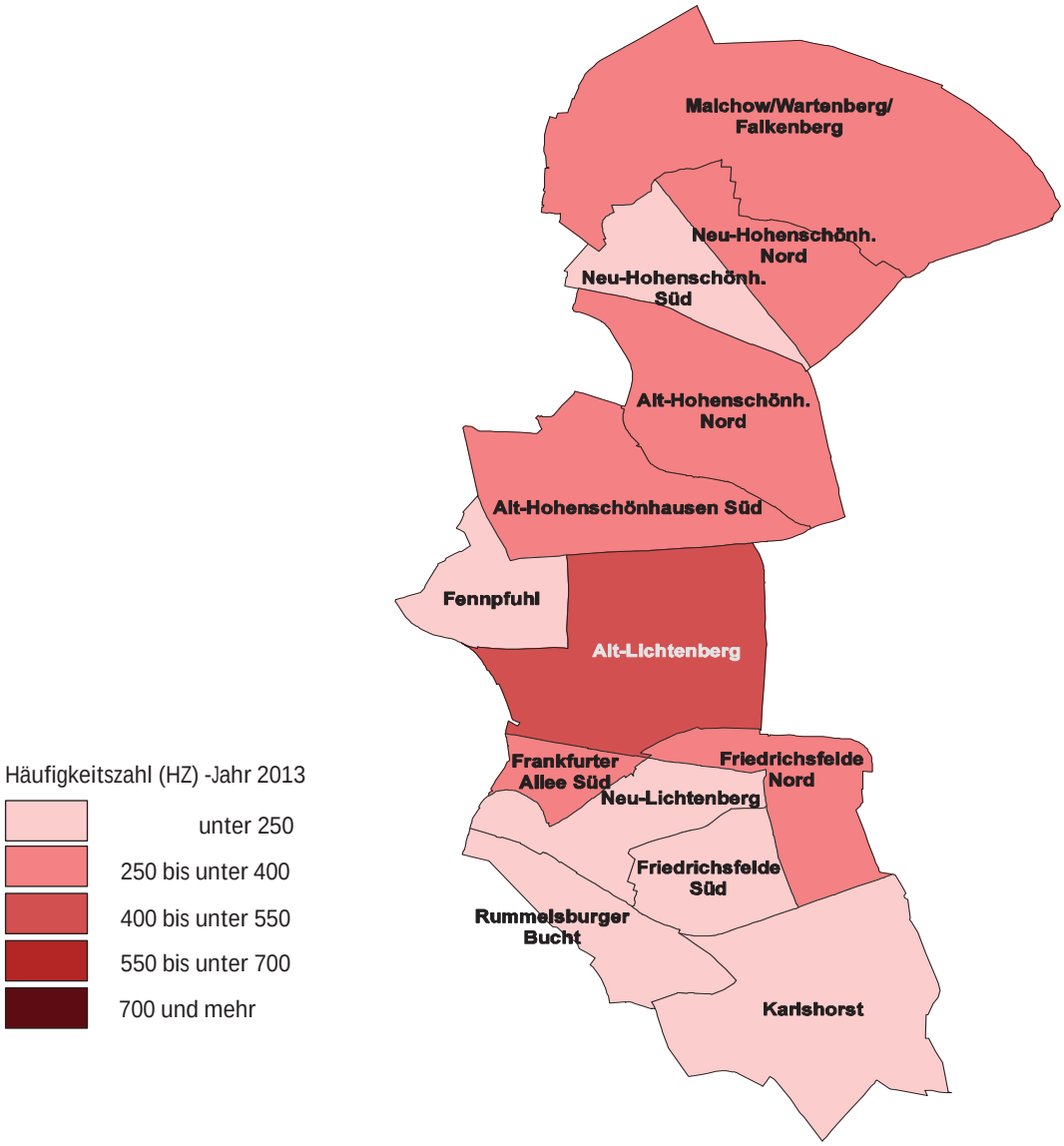

Nachstellung, Nötigung, Freiheitsberaubung, Bedrohung (PKS-Schlüssel 232000)

Bezirksregion	Jahr 2012		Jahr 2013		Zu-/Abnahme			
	erfasste Fälle	HZ	erfasste Fälle	HZ	Fälle absolut	Fälle in %	HZ absolut	HZ in %
Malchow/Warten-/Falkenberg.....	20	477	12	282	- 8	x	- 195	(- 40,9)
Neu-Hohenschönhausen Nord.....	93	338	81	293	- 12	x	- 45	(- 13,3)
Neu-Hohenschönhausen Süd.....	81	313	64	248	- 17	x	- 65	(- 20,8)
Alt-Hohenschönhausen Nord.....	42	312	48	356	6	x	44	(14,1)
Alt-Hohenschönhausen Süd.....	74	252	93	316	19	x	64	(25,4)
Fennpfuhl.....	90	284	78	244	- 12	x	- 40	(- 14,1)
Alt-Lichtenberg.....	119	495	109	437	- 10	- 8,4	- 58	- 11,7
Frankfurter Allee Süd.....	16	166	31	309	15	x	143	(86,1)
Neu-Lichtenberg.....	95	324	68	226	- 27	x	- 98	(- 30,2)
Friedrichsfelde Nord.....	41	308	50	370	9	x	62	(20,1)
Friedrichsfelde Süd.....	54	224	61	248	7	x	24	(10,7)
Rummelsburger Bucht.....	7	215	8	241	1	x	26	(12,1)
Karlshorst.....	41	182	44	189	3	x	7	(3,8)
nicht zuzuordnen.....	16		6					

Bezirk Berlin Reinickendorf

Nachstellung, Nötigung, Freiheitsberaubung, Bedrohung (Häufigkeitszahl)

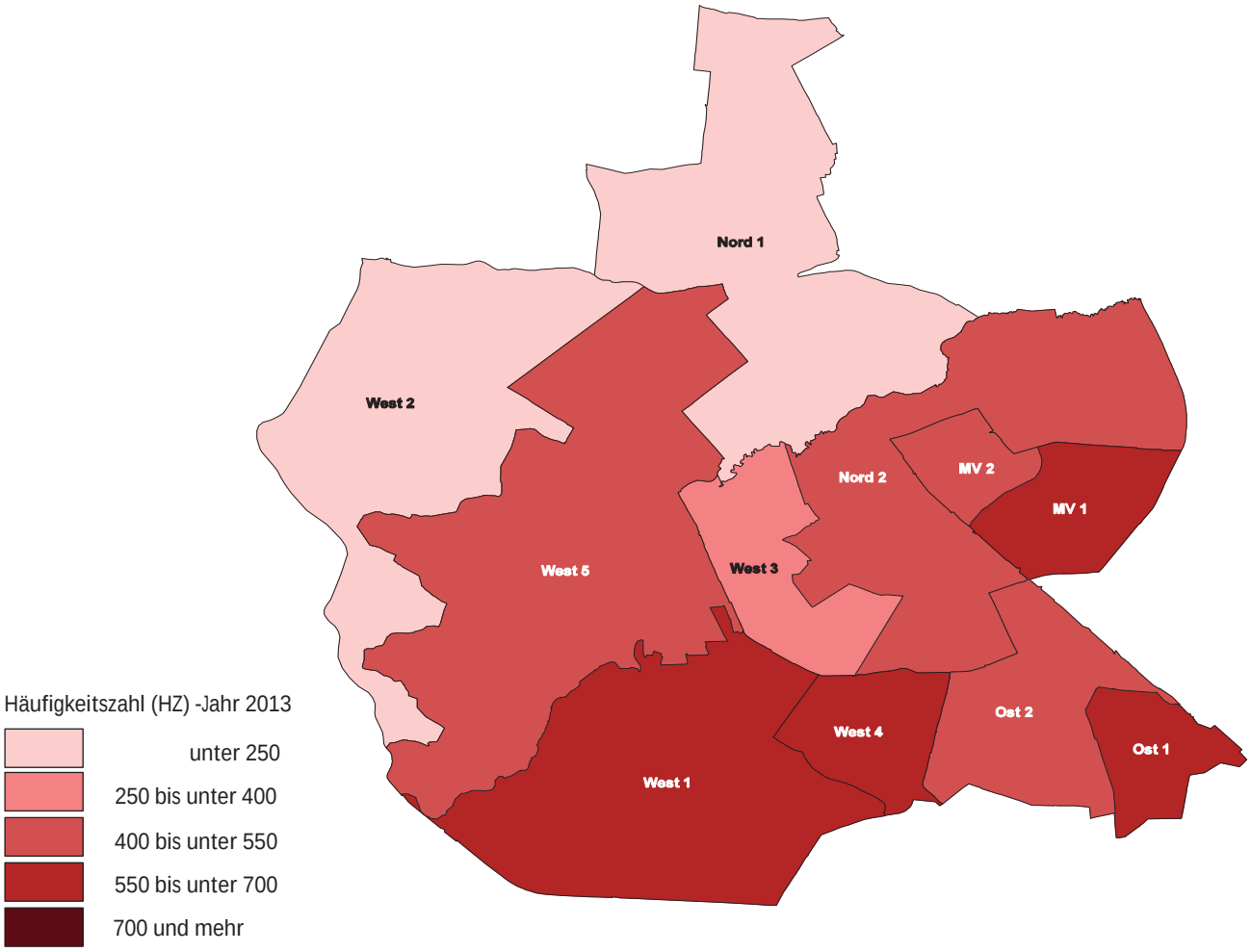

Nachstellung, Nötigung, Freiheitsberaubung, Bedrohung (PKS-Schlüssel 232000)

Bezirksregion	Jahr 2012		Jahr 2013		Zu-/Abnahme			
	erfasste Fälle	HZ	erfasste Fälle	HZ	Fälle		HZ	
					absolut	in %	absolut	in %
Ost 1	169	659	166	639	- 3	- 1,8	- 20	- 3,0
Ost 2	128	502	130	503	2	1,6	1	0,2
West 1	111	763	89	615	- 22	- 19,8	- 148	- 19,4
West 4	169	676	166	653	- 3	- 1,8	- 23	- 3,4
West 5	61	597	53	515	- 8	x	- 82	(- 13,7)
West 2	64	272	48	202	- 16	x	- 70	(- 25,7)
Nord 1	72	220	49	149	- 23	x	- 71	(- 32,3)
Nord 2	115	394	130	437	15	13,0	43	10,9
MV 1	199	562	219	602	20	10,1	40	7,1
MV 2	32	391	39	459	7	x	68	(17,4)
West 3	59	369	52	325	- 7	x	- 44	(- 11,9)
nicht zuzuordnen	12		7					

Berlin - Diebstahl -insgesamt- (Häufigkeitszahl)

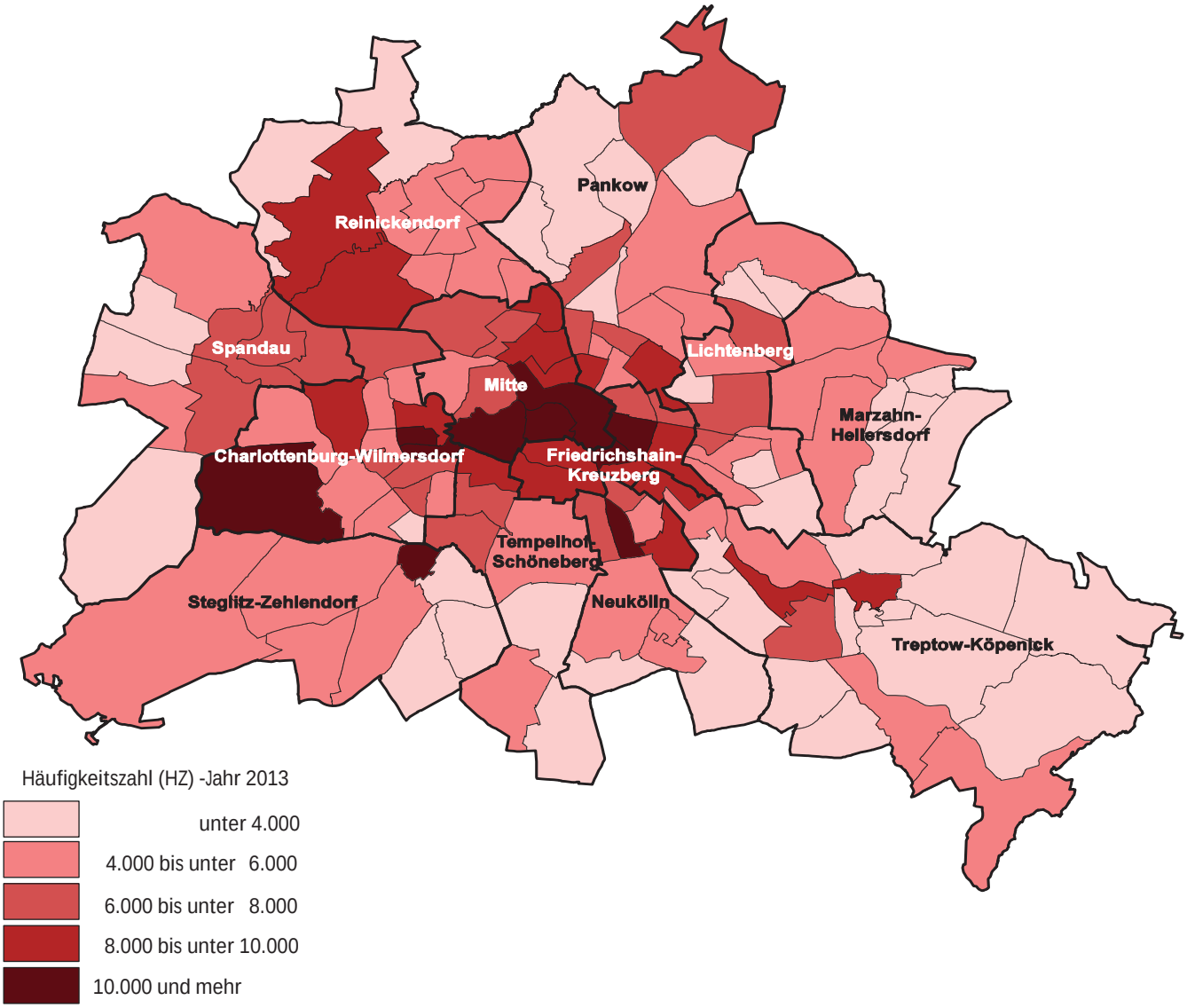

Diebstahl -insgesamt- (PKS-Schlüssel 3*****, 4*****)

Bezirk	Jahr 2012		Jahr 2013		Zu-/Abnahme			
	erfasste Fälle	HZ	erfasste Fälle	HZ	Fälle absolut	Fälle in %	HZ absolut	HZ in %
Mitte	36 486	10 873	39 314	11 442	2 828	7,8	569	5,2
Friedrichshain-Kreuzberg	22 050	8 262	24 474	9 024	2 424	11,0	762	9,2
Pankow	20 310	5 530	21 063	5 636	753	3,7	106	1,9
Charlottenburg-Wilmersdorf	24 061	7 596	25 733	8 021	1 672	6,9	425	5,6
Spandau	11 084	5 006	11 725	5 224	641	5,8	218	4,4
Steglitz-Zehlendorf	12 410	4 219	14 146	4 771	1 736	14,0	552	13,1
Tempelhof-Schöneberg	17 414	5 321	18 641	5 660	1 227	7,0	339	6,4
Neukölln	19 121	6 058	19 538	6 098	417	2,2	40	0,7
Treptow-Köpenick	9 881	4 078	10 769	4 401	888	9,0	323	7,9
Marzahn-Hellersdorf	9 714	3 881	9 830	3 885	116	1,2	4	0,1
Lichtenberg	11 911	4 608	12 074	4 600	163	1,4	- 8	- 0,2
Reinickendorf	12 898	5 244	13 110	5 260	212	1,6	16	0,3
Berlin, nicht zuzuordnen	5 672		5 862					
Berlin -Gesamt-	**213 012**	**6 319**	**226 279**	**6 647**	**13 267**	**6,2**	**328**	**5,2**

Bezirk Berlin Mitte

Diebstahl -insgesamt- (Häufigkeitszahl)

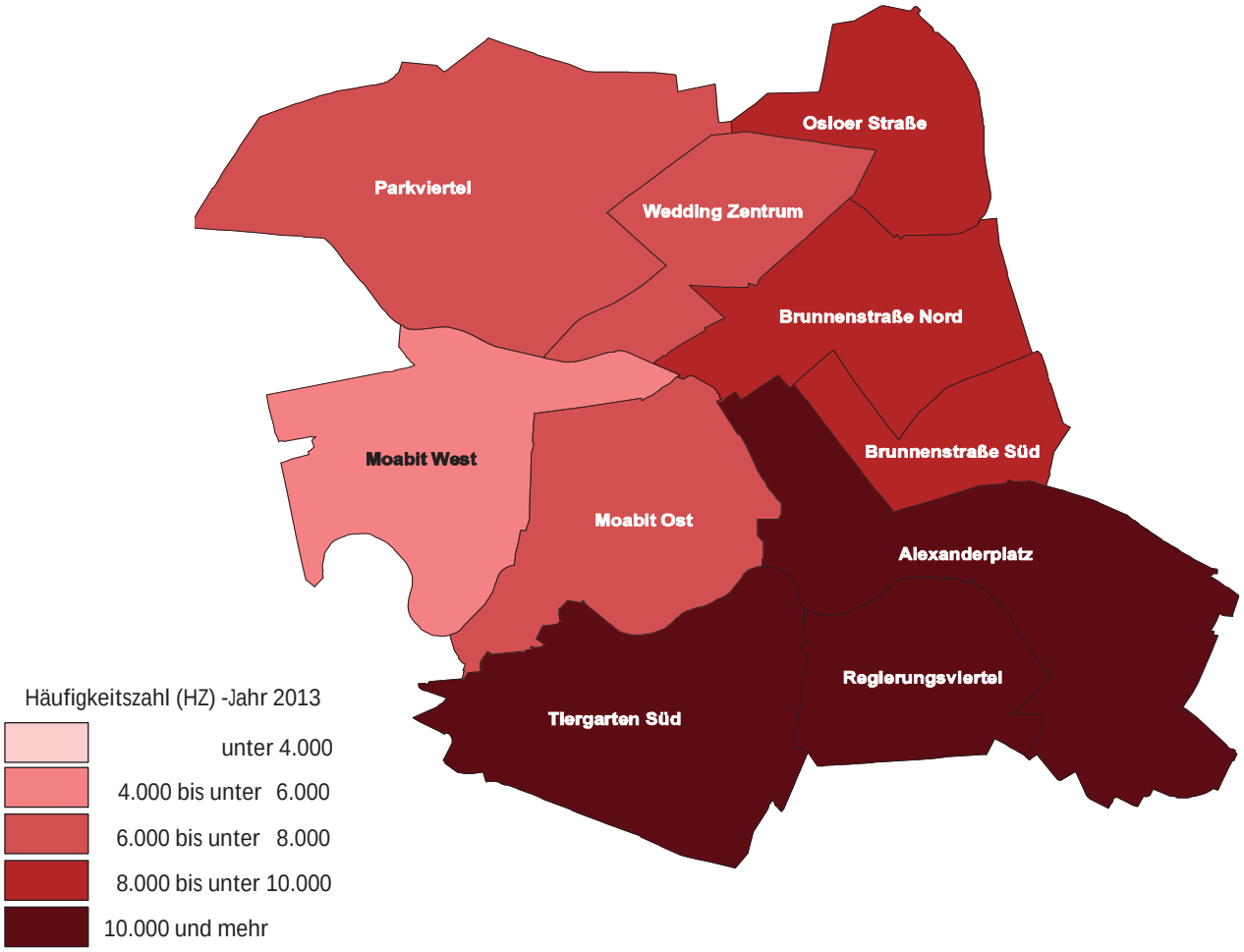

Diebstahl -insgesamt- (PKS-Schlüssel 3*****, 4*****)

Bezirksregion	Jahr 2012		Jahr 2013		Zu-/Abnahme			
	erfasste Fälle	HZ	erfasste Fälle	HZ	Fälle		HZ	
					absolut	in %	absolut	in %
Tiergarten Süd	2 263	17 960	2 652	20 384	389	17,2	2 424	13,5
Regierungsviertel	3 203	34 941	3 862	41 536	659	20,6	6 595	18,9
Alexanderplatz	8 988	19 045	10 165	21 117	1 177	13,1	2 072	10,9
Brunnenstraße Süd	1 916	7 494	2 503	9 424	587	30,6	1 930	25,8
Moabit West	2 470	5 897	2 441	5 707	- 29	- 1,2	- 190	- 3,2
Moabit Ost	2 290	6 575	2 536	7 181	246	10,7	606	9,2
Osloer Straße	3 666	10 460	3 540	9 780	- 126	- 3,4	- 680	- 6,5
Brunnenstraße Nord	2 928	8 297	3 248	9 064	320	10,9	767	9,2
Parkviertel	2 879	6 946	2 924	6 904	45	1,6	- 42	- 0,6
Wedding Zentrum	3 396	6 464	3 307	6 111	- 89	- 2,6	- 353	- 5,5
nicht zuzuordnen	2 487	-	2 136	-				

Bezirk Berlin Friedrichshain-Kreuzberg

Diebstahl -insgesamt- (Häufigkeitszahl)

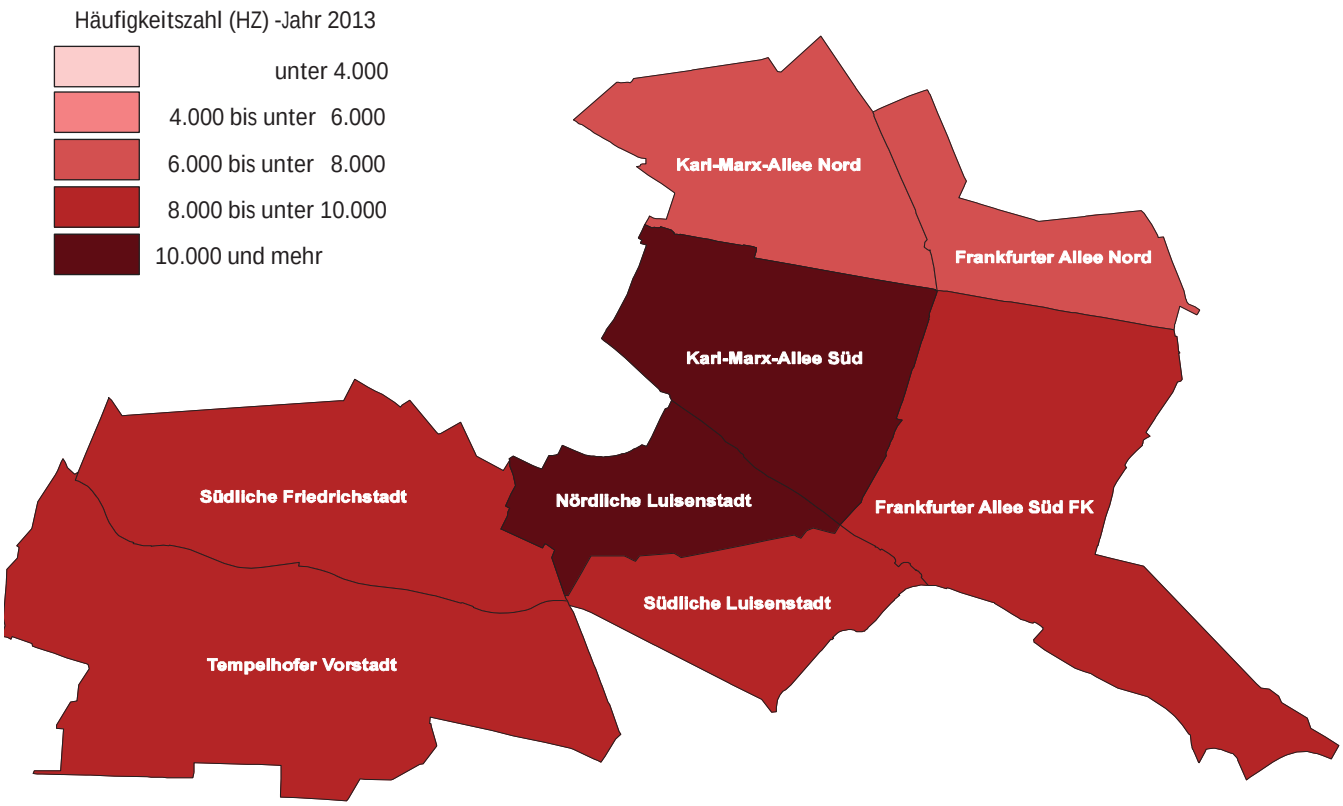

Diebstahl -insgesamt- (PKS-Schlüssel 3*****, 4*****)

Bezirksregion	Jahr 2012		Jahr 2013		Zu-/Abnahme			
	erfasste Fälle	HZ	erfasste Fälle	HZ	Fälle		HZ	
					absolut	in %	absolut	in %
Südliche Friedrichstadt.....	2 928	7 517	3 394	8 591	466	15,9	1 074	14,3
Tempelhofer Vorstadt.....	5 170	8 487	5 097	8 227	- 73	- 1,4	- 260	- 3,1
Nördliche Luisenstadt.....	2 330	10 431	2 805	12 441	475	20,4	2 010	19,3
Südliche Luisenstadt.....	1 932	7 403	2 474	9 358	542	28,1	1 955	26,4
Karl-Marx-Allee Nord.....	1 242	5 580	1 361	6 054	119	9,6	474	8,5
Karl-Marx-Allee Süd.....	2 725	11 878	2 844	12 148	119	4,4	270	2,3
Frankfurter Allee Nord.....	1 528	5 625	1 769	6 410	241	15,8	785	14,0
Frankfurter Allee Süd FK.....	3 588	7 767	4 070	8 612	482	13,4	845	10,9
nicht zuzuordnen.....	607		660					

Bezirk Berlin Pankow

Diebstahl -insgesamt- (Häufigkeitszahl)

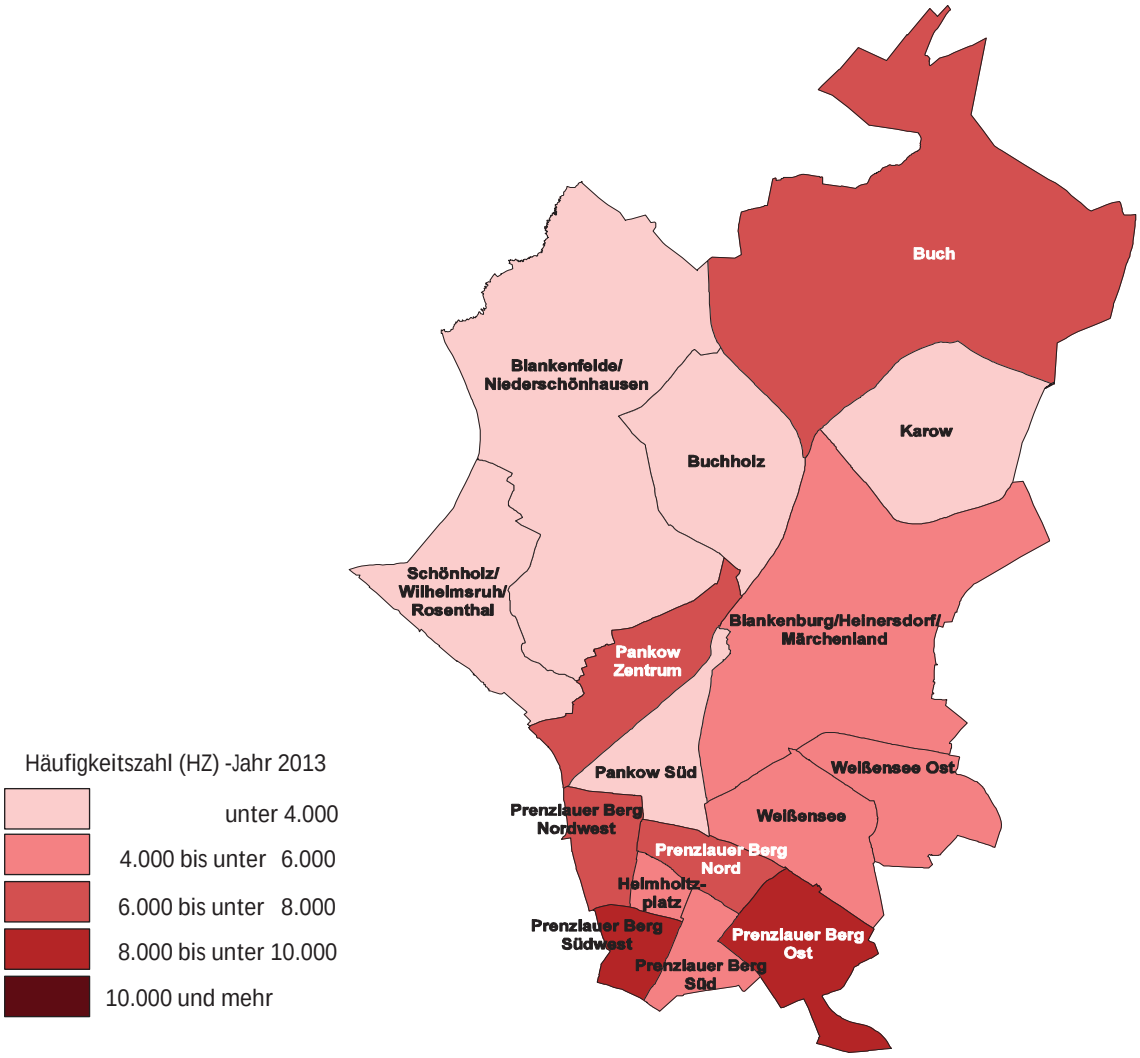

Diebstahl -insgesamt- (PKS-Schlüssel 3*****, 4*****)

Bezirksregion	Jahr 2012		Jahr 2013		Zu-/Abnahme			
	erfasste Fälle	HZ	erfasste Fälle	HZ	Fälle absolut	Fälle in %	HZ absolut	HZ in %
Buch	1 035	7 938	858	6 334	- 177	- 17,1	- 1 604	- 20,2
Blankenfelde/Niederschönhausen	782	3 089	894	3 440	112	14,3	351	11,4
Buchholz	456	2 717	483	2 843	27	5,9	126	4,6
Karow	481	2 573	449	2 411	- 32	- 6,7	- 162	- 6,3
Blankenburg/Heinersdorf	898	6 357	824	5 827	- 74	- 8,2	- 530	- 8,3
Pankow Süd	1 235	3 880	1 211	3 730	- 24	- 1,9	- 150	- 3,9
Schönholz/Wilhelmsruh/Rosenthal	599	3 497	604	3 520	5	0,8	23	0,7
Pankow Zentrum	2 089	6 438	2 164	6 493	75	3,6	55	0,9
Weißensee	1 537	4 665	1 655	4 924	118	7,7	259	5,6
Weißensee Ost	610	4 066	626	4 137	16	2,6	71	1,7
Prenzlauer Berg Nordwest	1 716	7 265	1 718	7 084	2	0,1	- 181	- 2,5
Prenzlauer Berg Nord	1 870	7 245	1 914	7 337	44	2,4	92	1,3
Helmholtzplatz	1 215	5 730	1 280	5 908	65	5,3	178	3,1
Prenzlauer Berg Ost	2 063	8 493	2 151	8 671	88	4,3	178	2,1
Prenzlauer Berg Südwest	2 016	8 318	2 201	8 872	185	9,2	554	6,7
Prenzlauer Berg Süd	1 393	4 522	1 633	5 244	240	17,2	722	16,0
nicht zuzuordnen	315		398					

Bezirk Berlin Charlottenburg-Wilmersdorf

Diebstahl -insgesamt- (Häufigkeitszahl)

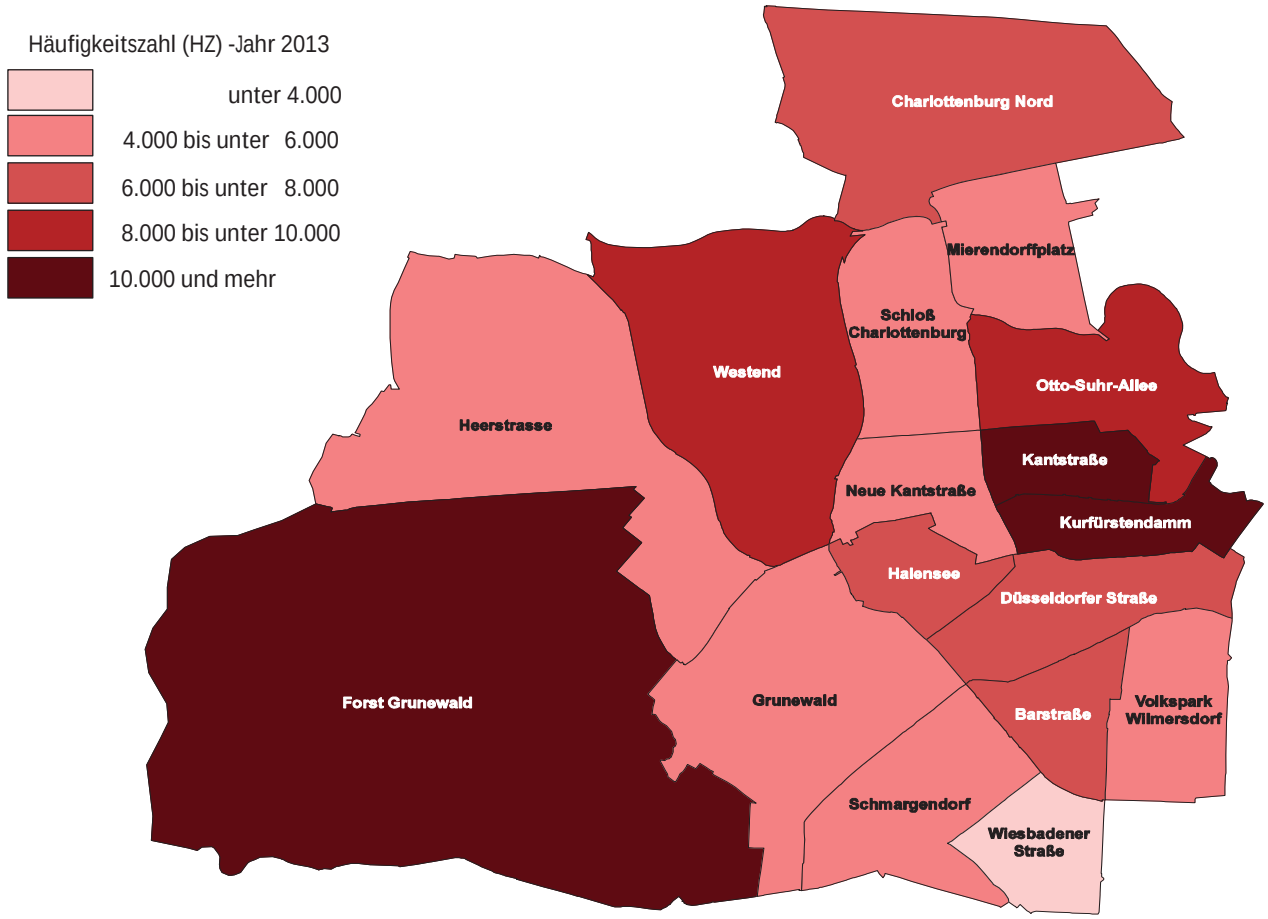

Diebstahl -insgesamt- (PKS-Schlüssel 3*****, 4*****)

Bezirksregion	Jahr 2012		Jahr 2013		Zu-/Abnahme			
	erfasste Fälle	HZ	erfasste Fälle	HZ	Fälle absolut	Fälle in %	HZ absolut	HZ in %
Charlottenburg Nord.....	1 006	5 562	1 119	6 060	113	11,2	498	9,0
Heerstraße.....	579	4 632	720	5 708	141	24,4	1 076	23,2
Westend.....	1 974	7 540	2 344	8 798	370	18,7	1 258	16,7
Schloß Charlottenburg.....	1 140	4 925	1 205	5 143	65	5,7	218	4,4
Mierendorffplatz.....	893	6 276	846	5 801	- 47	- 5,3	- 475	- 7,6
Otto-Suhr-Allee.....	2 273	8 922	2 260	8 765	- 13	- 0,6	- 157	- 1,8
Neue Kantstraße.....	1 283	5 595	1 384	5 971	101	7,9	376	6,7
Kantstraße.....	2 565	12 534	2 798	13 503	233	9,1	969	7,7
Kurfürstendamm.....	4 140	28 430	4 299	29 471	159	3,8	1 041	3,7
Halensee.....	949	6 685	1 011	7 009	62	6,5	324	4,8
Grunewald.....	867	4 844	950	5 214	83	9,6	370	7,6
Schmargendorf.....	731	5 292	816	5 868	85	11,6	576	10,9
Wiesbadener Straße.....	642	3 562	656	3 631	14	2,2	69	1,9
Düsseldorfer Straße.....	1 779	6 066	1 970	6 622	191	10,7	556	9,2
Barstraße.....	774	5 737	903	6 654	129	16,7	917	16,0
Volkspark Wilmersdorf.....	1 656	5 118	1 690	5 153	34	2,1	35	0,7
Forst Grunewald.....	94		68		- 26	x		
nicht zuzuordnen.....	716		694					

Bezirk Berlin Spandau

Diebstahl -insgesamt- (Häufigkeitszahl)

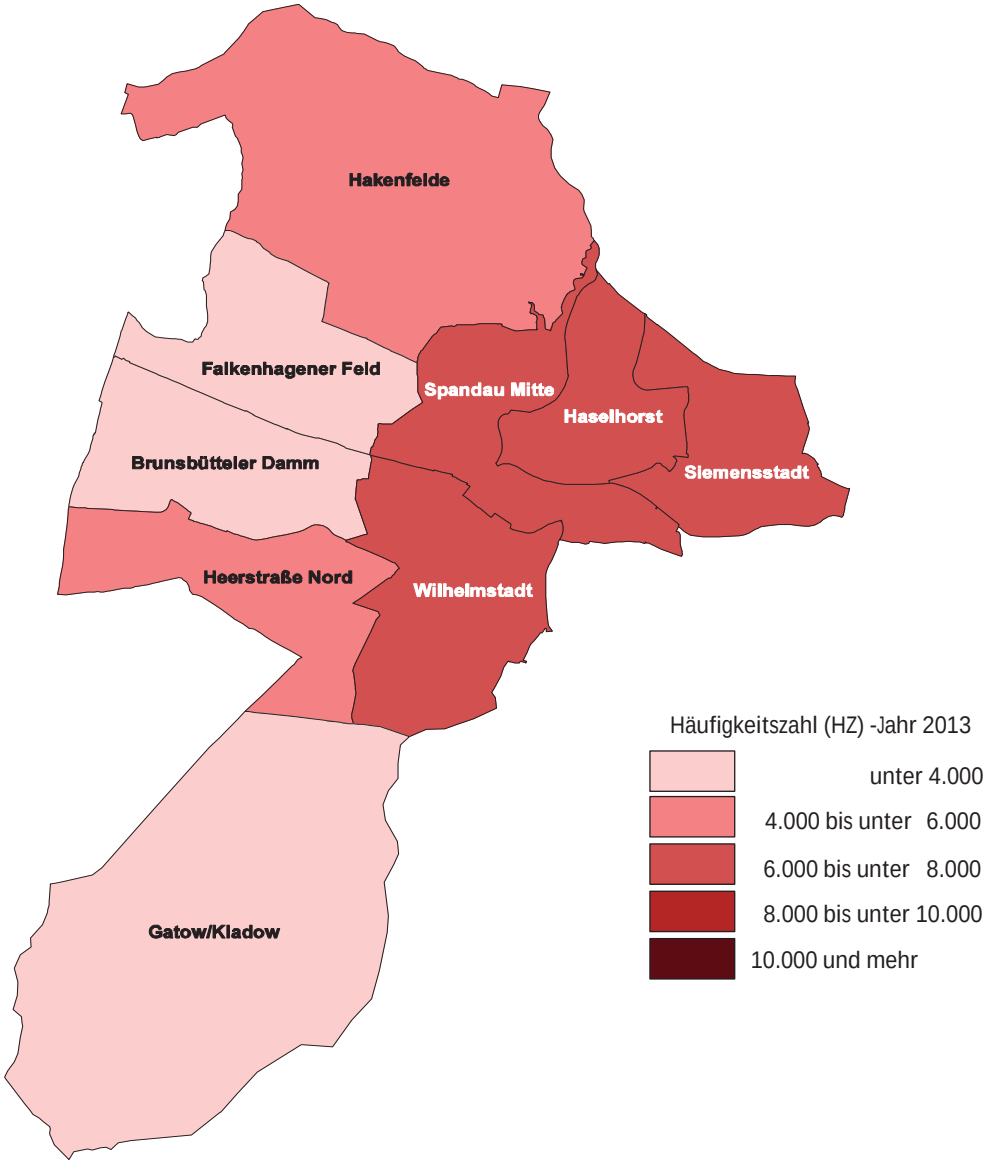

Diebstahl -insgesamt- (PKS-Schlüssel 3*****, 4*****)

Bezirksregion	Jahr 2012		Jahr 2013		Zu-/Abnahme			
	erfasste Fälle	HZ	erfasste Fälle	HZ	Fälle		HZ	
					absolut	in %	absolut	in %
Hakenfelde.....	930	4 104	1 005	4 426	75	8,1	322	7,8
Falkenhagener Feld.....	1 157	2 966	1 170	2 983	13	1,1	17	0,6
Spandau Mitte.....	2 371	7 215	2 471	7 331	100	4,2	116	1,6
Brunsbütteler Damm.....	772	3 335	911	3 941	139	18,0	606	18,2
Heerstraße Nord.....	1 108	4 152	1 124	4 197	16	1,4	45	1,1
Wilhelmstadt.....	2 158	6 368	2 470	7 188	312	14,5	820	12,9
Haselhorst.....	1 143	8 302	1 099	7 614	- 44	- 3,8	- 688	- 8,3
Siemensstadt.....	739	6 358	775	6 464	36	4,9	106	1,7
Gatow/Kladow.....	435	2 448	456	2 513	21	4,8	65	2,7
nicht zuzuordnen.....	271		244					

Bezirk Berlin Steglitz-Zehlendorf

Diebstahl -insgesamt- (Häufigkeitszahl)

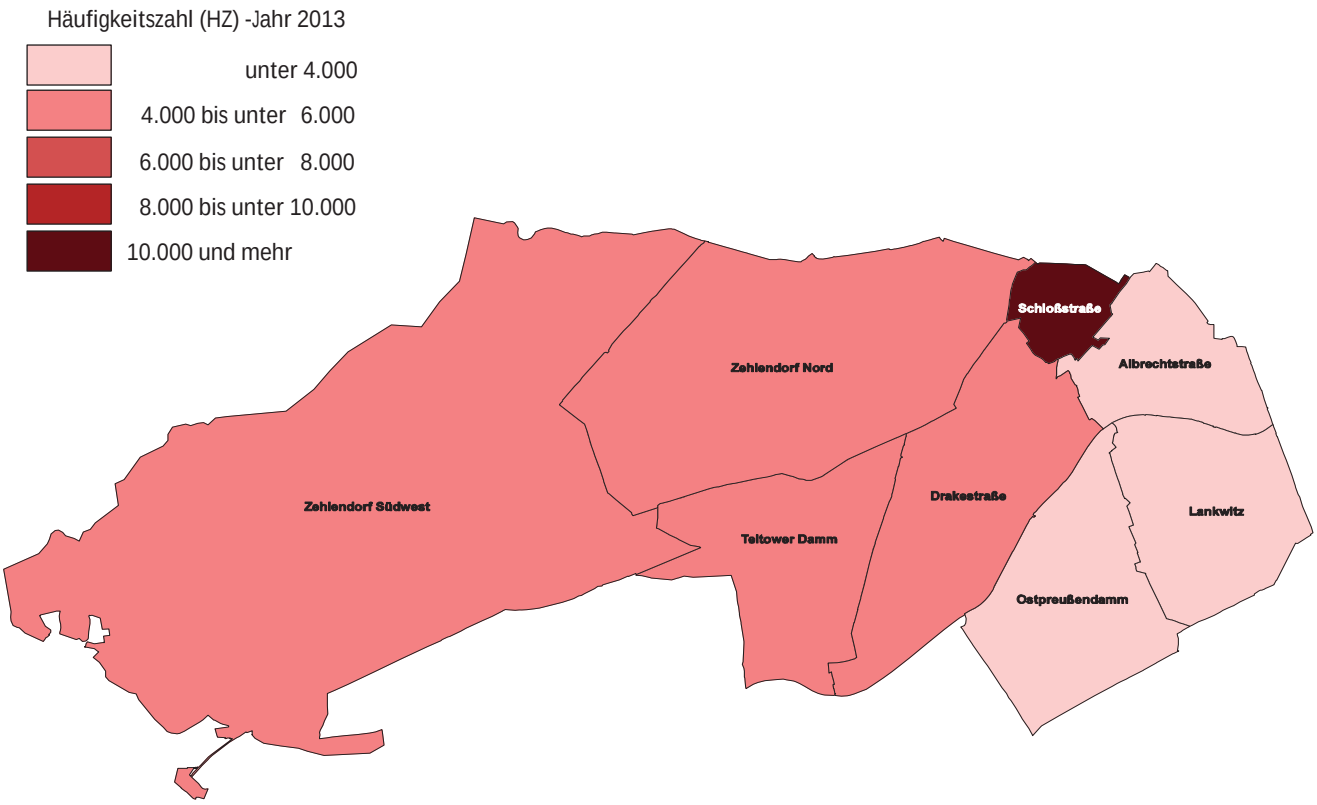

Diebstahl -insgesamt- (PKS-Schlüssel 3*****, 4*****)

Bezirksregion	Jahr 2012		Jahr 2013		Zu-/Abnahme			
	erfasste Fälle	HZ	erfasste Fälle	HZ	Fälle		HZ	
					absolut	in %	absolut	in %
Schloßstraße.....	2 375	11 098	2 879	13 320	504	21,2	2 222	20,0
Albrechtstraße.....	1 581	3 079	1 617	3 124	36	2,3	45	1,5
Lankwitz.....	1 084	2 622	1 315	3 148	231	21,3	526	20,1
Ostpreußendamm.....	1 165	3 361	1 286	3 677	121	10,4	316	9,4
Teltower Damm.....	1 254	3 837	1 403	4 281	149	11,9	444	11,6
Drakestraße.....	1 749	3 827	1 936	4 162	187	10,7	335	8,8
Zehlendorf Südwest.....	1 006	3 943	1 289	5 046	283	28,1	1 103	28,0
Zehlendorf Nord.....	1 952	4 701	2 207	5 317	255	13,1	616	13,1
nicht zuzuordnen.....	244		214					

Bezirk Berlin Tempelhof-Schöneberg

Diebstahl -insgesamt- (Häufigkeitszahl)

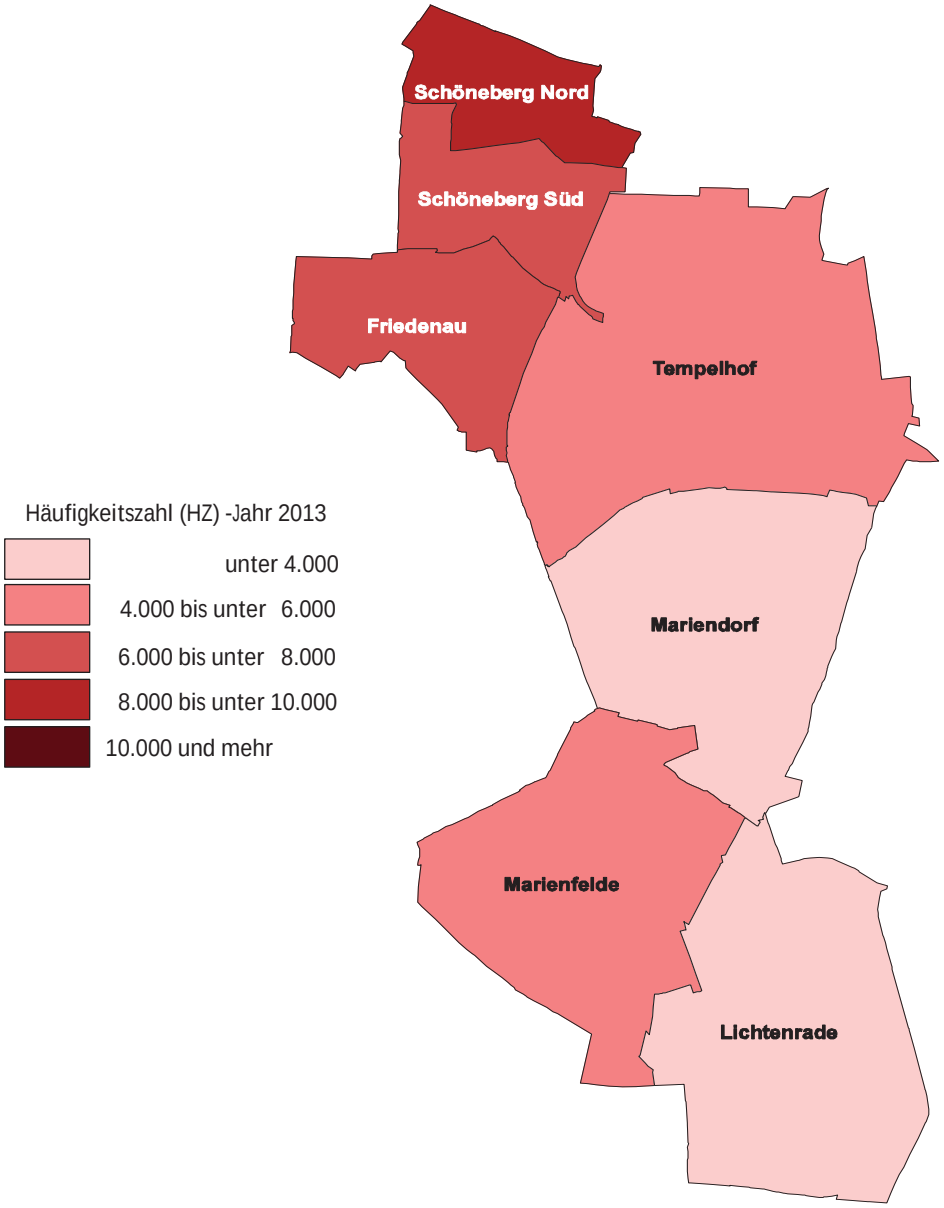

Diebstahl -insgesamt- (PKS-Schlüssel 3*****, 4*****)

Bezirksregion	Jahr 2012		Jahr 2013		Zu-/Abnahme			
	erfasste Fälle	HZ	erfasste Fälle	HZ	Fälle		HZ	
					absolut	in %	absolut	in %
Schöneberg Nord.....	4 048	8 593	4 449	9 477	401	9,9	884	10,3
Schöneberg Süd.....	2 699	5 679	2 900	6 082	201	7,4	403	7,1
Friedenau.....	2 170	4 931	2 909	6 552	739	34,1	1 621	32,9
Tempelhof.....	3 645	6 183	3 581	5 964	- 64	- 1,8	- 219	- 3,5
Mariendorf.....	1 871	3 755	1 886	3 772	15	0,8	17	0,5
Marienfelde.....	1 357	4 459	1 310	4 289	- 47	- 3,5	- 170	- 3,8
Lichtenrade.....	1 267	2 562	1 231	2 477	- 36	- 2,8	- 85	- 3,3
nicht zuzuordnen.....	357		375					

Bezirk Berlin Neukölln

Diebstahl -insgesamt- (Häufigkeitszahl)

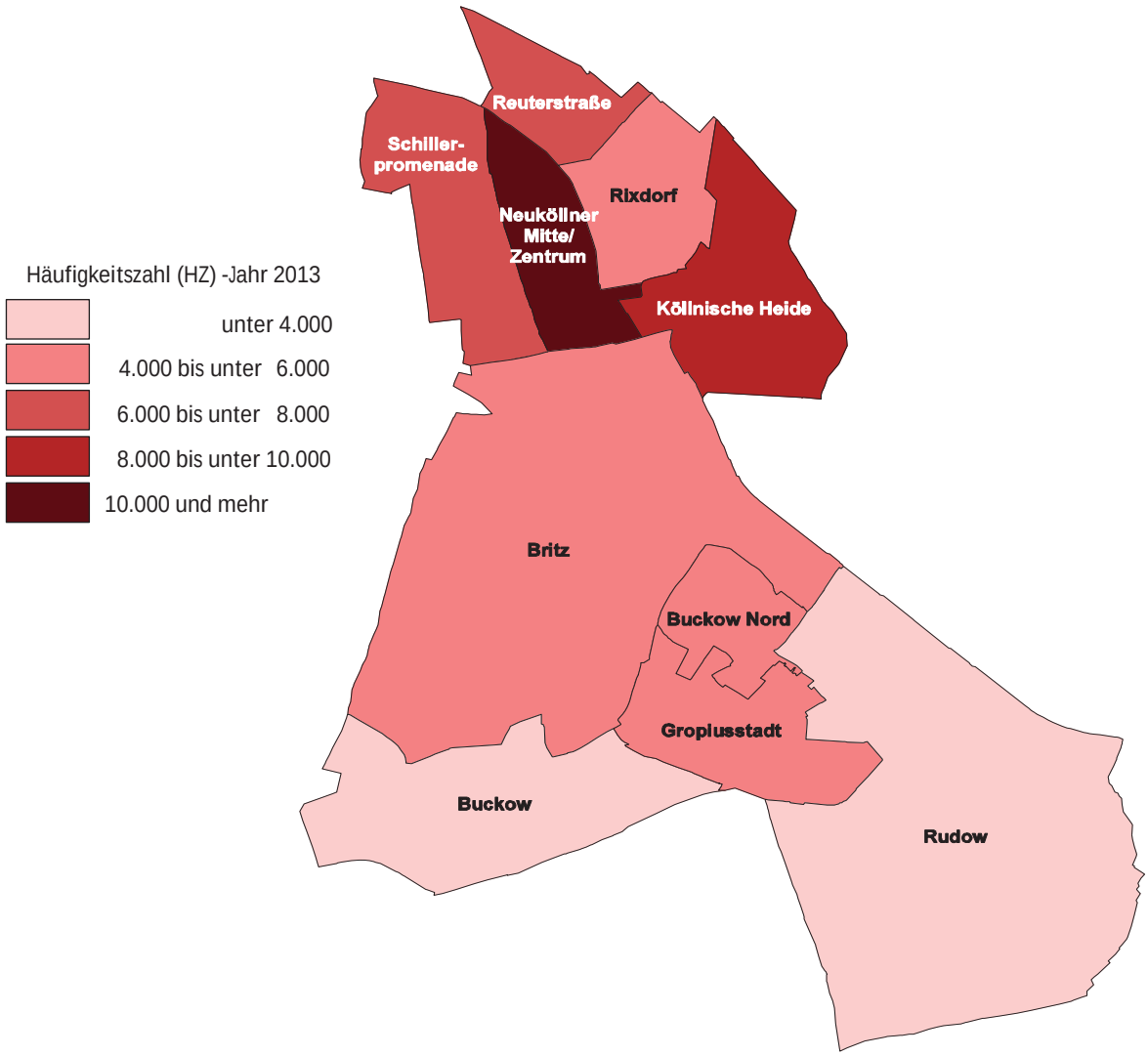

Diebstahl -insgesamt- (PKS-Schlüssel 3*****, 4*****)

Bezirksregion	Jahr 2012		Jahr 2013		Zu-/Abnahme			
	erfasste Fälle	HZ	erfasste Fälle	HZ	Fälle absolut	Fälle in %	HZ absolut	HZ in %
Schillerpromenade	2 400	7 760	2 193	6 947	- 207	- 8,6	- 813	- 10,5
Neuköllner Mitte/Zentrum	4 181	11 332	4 367	11 573	186	4,4	241	2,1
Reuterstraße	2 679	6 899	2 808	7 064	129	4,8	165	2,4
Rixdorf	2 088	5 372	2 211	5 594	123	5,9	222	4,1
Köllnische Heide	1 190	8 074	1 339	8 904	149	12,5	830	10,3
Britz	2 132	5 263	2 123	5 166	- 9	- 0,4	- 97	- 1,8
Buckow	634	2 296	687	2 467	53	8,4	171	7,4
Gropiusstadt	1 942	5 386	1 775	4 882	- 167	- 8,6	- 504	- 9,4
Buckow Nord	409	4 400	461	4 921	52	12,7	521	11,8
Rudow	1 256	2 996	1 344	3 191	88	7,0	195	6,5
nicht zuzuordnen	210		230					

Bezirk Berlin Treptow-Köpenick

Diebstahl -insgesamt- (Häufigkeitszahl)

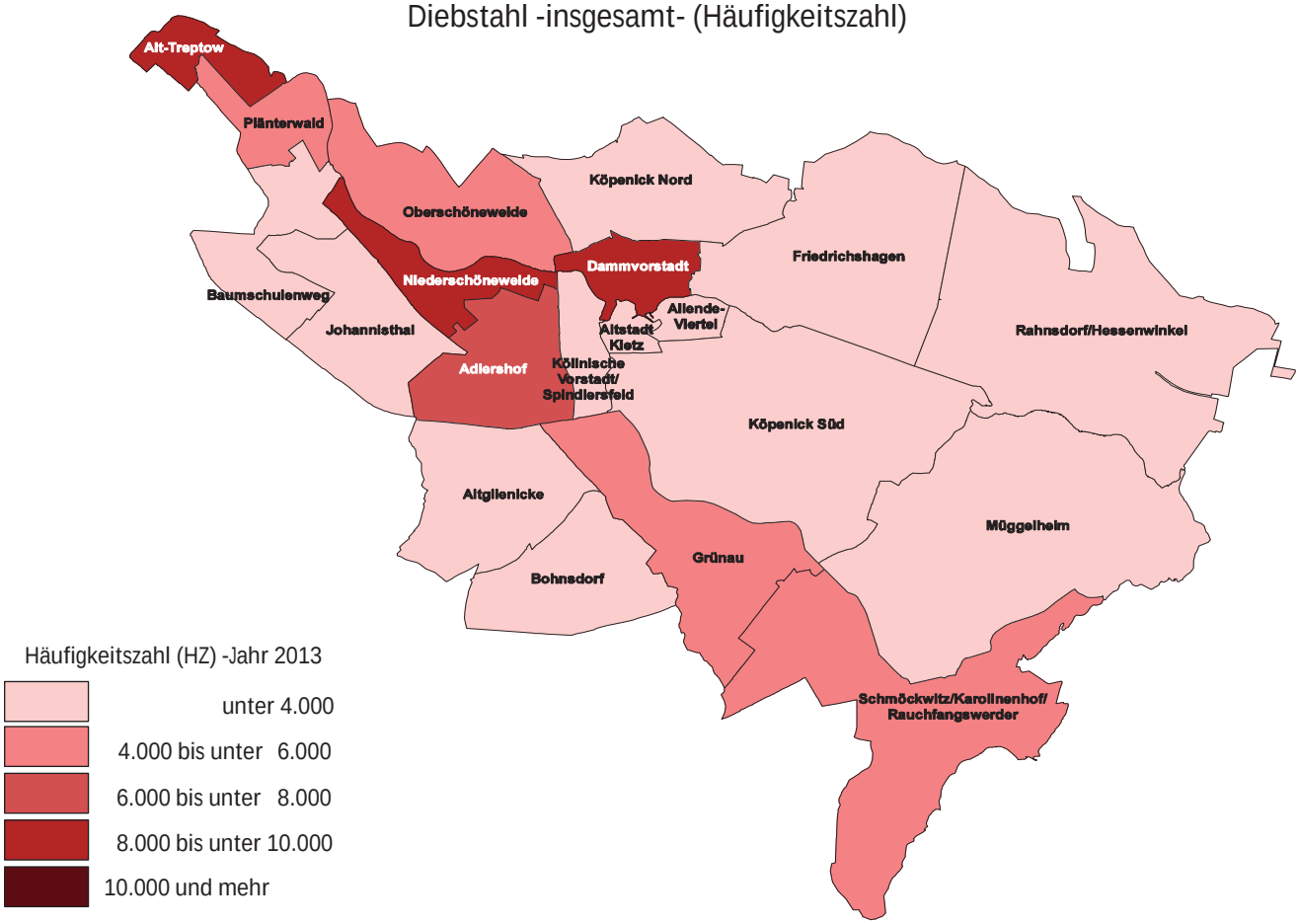

Diebstahl -insgesamt- (PKS-Schlüssel 3*****, 4*****)

Bezirksregion	Jahr 2012		Jahr 2013		Zu-/Abnahme			
	erfasste Fälle	HZ	erfasste Fälle	HZ	Fälle		HZ	
					absolut	in %	absolut	in %
Alt-Treptow	1 028	9 409	1 069	9 633	41	4,0	224	2,4
Plänterwald	500	4 636	594	5 483	94	18,8	847	18,3
Baumschulenweg	619	3 592	684	3 924	65	10,5	332	9,2
Johannisthal	537	2 931	619	3 358	82	15,3	427	14,6
Oberschöneweide	838	4 373	1 066	5 407	228	27,2	1 034	23,6
Niederschöneweide	871	8 336	903	8 494	32	3,7	158	1,9
Adlershof	961	6 246	960	6 152	- 1	- 0,1	- 94	- 1,5
Kölln. Vorstadt/Spindlersf.	389	3 952	327	3 268	- 62	- 15,9	- 684	- 17,3
Altglienicke	539	2 110	634	2 450	95	17,6	340	16,1
Bohnsdorf	340	2 856	352	2 918	12	3,5	62	2,2
Grünau	242	4 483	233	4 158	- 9	- 3,7	- 325	- 7,2
Schmöckwitz/Karolinenhof	146	3 594	171	4 244	25	17,1	650	18,1
Köpenick Süd	401	2 567	361	2 322	- 40	- 10,0	- 245	- 9,5
Allende-Viertel	194	3 177	198	3 235	4	2,1	58	1,8
Altstadt Kietz	224	3 261	220	3 170	- 4	- 1,8	- 91	- 2,8
Müggelheim	113	1 737	107	1 636	- 6	- 5,3	- 101	- 5,8
Friedrichshagen	516	2 952	560	3 206	44	8,5	254	8,6
Rahnsdorf/Hessenwinkel	290	3 235	348	3 884	58	20,0	649	20,1
Dammvorstadt	568	6 027	807	8 474	239	42,1	2 447	40,6
Köpenick Nord	245	1 993	281	2 290	36	14,7	297	14,9
nicht zuzuordnen	320		275					

Bezirk Berlin Marzahn-Hellersdorf

Diebstahl -insgesamt- (Häufigkeitszahl)

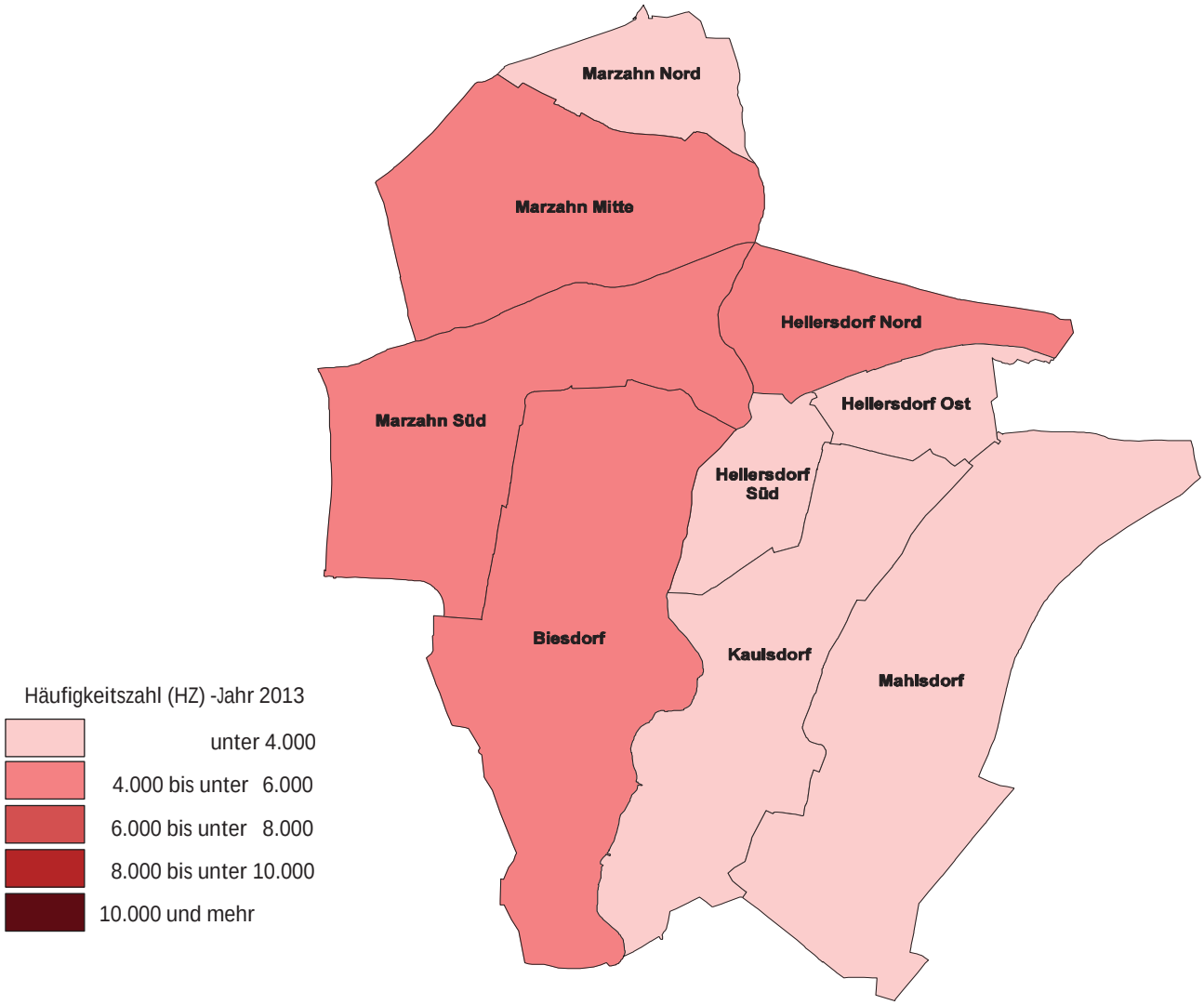

Diebstahl -insgesamt- (PKS-Schlüssel 3*****, 4*****)

Bezirksregion	Jahr 2012		Jahr 2013		Zu-/Abnahme			
	erfasste Fälle	HZ	erfasste Fälle	HZ	Fälle		HZ	
					absolut	in %	absolut	in %
Marzahn Nord	751	3 315	795	3 467	44	5,9	152	4,6
Marzahn Mitte	2 109	4 667	1 973	4 326	- 136	- 6,4	- 341	- 7,3
Marzahn Süd	1 534	4 248	1 631	4 458	97	6,3	210	4,9
Hellersdorf Nord	1 576	4 806	1 465	4 399	- 111	- 7,0	- 407	- 8,5
Hellersdorf Ost	598	3 242	568	3 009	- 30	- 5,0	- 233	- 7,2
Hellersdorf Süd	704	2 902	657	2 690	- 47	- 6,7	- 212	- 7,3
Biesdorf	1 153	4 585	1 260	4 940	107	9,3	355	7,7
Kaulsdorf	465	2 486	504	2 702	39	8,4	216	8,7
Mahlsdorf	607	2 249	734	2 708	127	20,9	459	20,4
nicht zuzuordnen	217		243					

Bezirk Berlin Lichtenberg

Diebstahl -insgesamt- (Häufigkeitszahl)

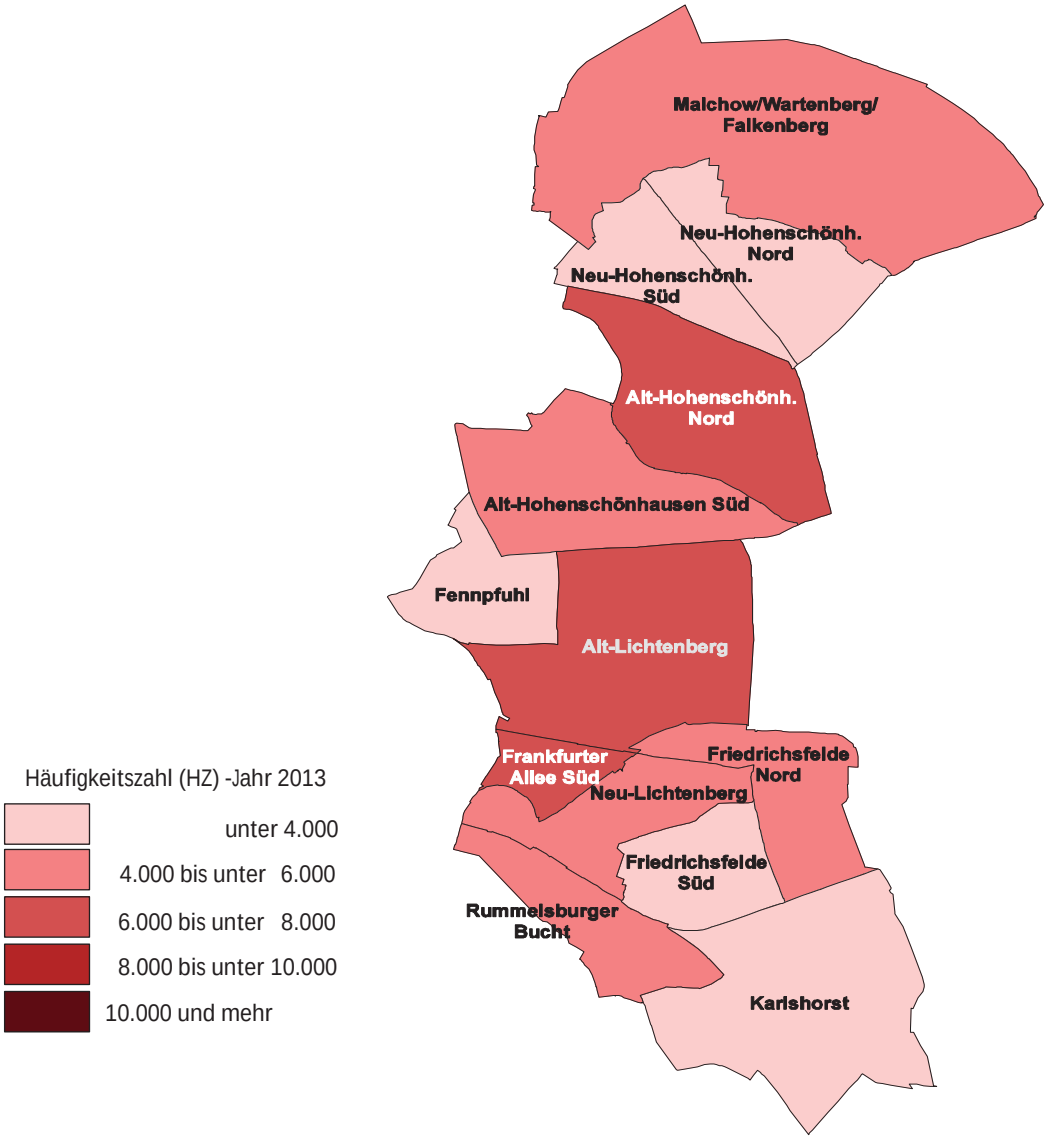

Diebstahl -insgesamt- (PKS-Schlüssel 3*****, 4*****)

Bezirksregion	Jahr 2012		Jahr 2013		Zu-/Abnahme			
	erfasste Fälle	HZ	erfasste Fälle	HZ	Fälle absolut	Fälle in %	HZ absolut	HZ in %
Malchow/Warten-/Falkenberg.....	178	4 246	246	5 791	68	38,2	1 545	36,4
Neu-Hohenschönhausen Nord.....	826	3 005	802	2 897	- 24	- 2,9	- 108	- 3,6
Neu-Hohenschönhausen Süd.....	1 027	3 969	980	3 791	- 47	- 4,6	- 178	- 4,5
Alt-Hohenschönhausen Nord.....	770	5 716	845	6 264	75	9,7	548	9,6
Alt-Hohenschönhausen Süd.....	1 243	4 230	1 367	4 640	124	10,0	410	9,7
Fennpfuhl.....	1 232	3 884	1 170	3 655	- 62	- 5,0	- 229	- 5,9
Alt-Lichtenberg.....	2 071	8 623	1 943	7 792	- 128	- 6,2	- 831	- 9,6
Frankfurter Allee Süd.....	578	5 983	646	6 445	68	11,8	462	7,7
Neu-Lichtenberg.....	1 286	4 379	1 382	4 600	96	7,5	221	5,0
Friedrichsfelde Nord.....	683	5 125	716	5 296	33	4,8	171	3,3
Friedrichsfelde Süd.....	790	3 277	743	3 024	- 47	- 5,9	- 253	- 7,7
Rummelsburger Bucht.....	227	6 957	173	5 219	- 54	- 23,8	- 1 738	- 25,0
Karlshorst.....	694	3 073	852	3 655	158	22,8	582	18,9
nicht zuzuordnen.....	306		209					

Bezirk Berlin Reinickendorf

Diebstahl -insgesamt- (Häufigkeitszahl)

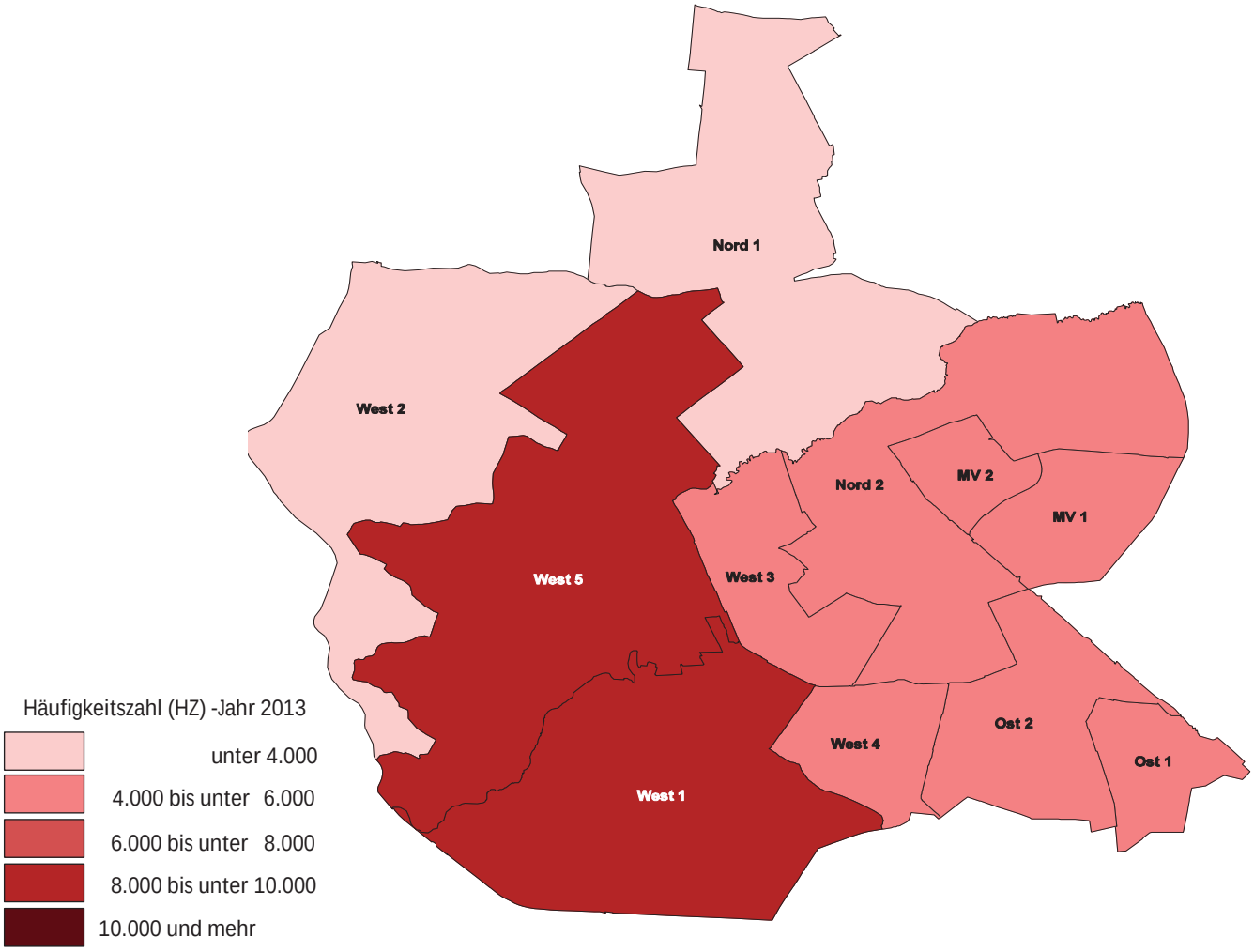

Diebstahl -insgesamt- (PKS-Schlüssel 3*****, 4*****)

Bezirksregion	Jahr 2012		Jahr 2013		Zu-/Abnahme			
	erfasste Fälle	HZ	erfasste Fälle	HZ	Fälle absolut	Fälle in %	HZ absolut	HZ in %
Ost 1	1 119	4 362	1 183	4 553	64	5,7	191	4,4
Ost 2	1 525	5 979	1 433	5 542	- 92	- 6,0	- 437	- 7,3
West 1	1 556	10 696	1 446	9 994	- 110	- 7,1	- 702	- 6,6
West 4	1 353	5 414	1 375	5 409	22	1,6	- 5	- 0,1
West 5	1 041	10 190	969	9 414	- 72	- 6,9	- 776	- 7,6
West 2	567	2 406	639	2 687	72	12,7	281	11,7
Nord 1	1 059	3 240	1 180	3 595	121	11,4	355	11,0
Nord 2	1 464	5 015	1 631	5 479	167	11,4	464	9,3
MV 1	2 013	5 684	1 986	5 460	- 27	- 1,3	- 224	- 3,9
MV 2	429	5 236	487	5 728	58	13,5	492	9,4
West 3	618	3 869	645	4 034	27	4,4	165	4,3
nicht zuzuordnen	154		136					

Berlin - Diebstahl von Kraftwagen (Häufigkeitszahl)

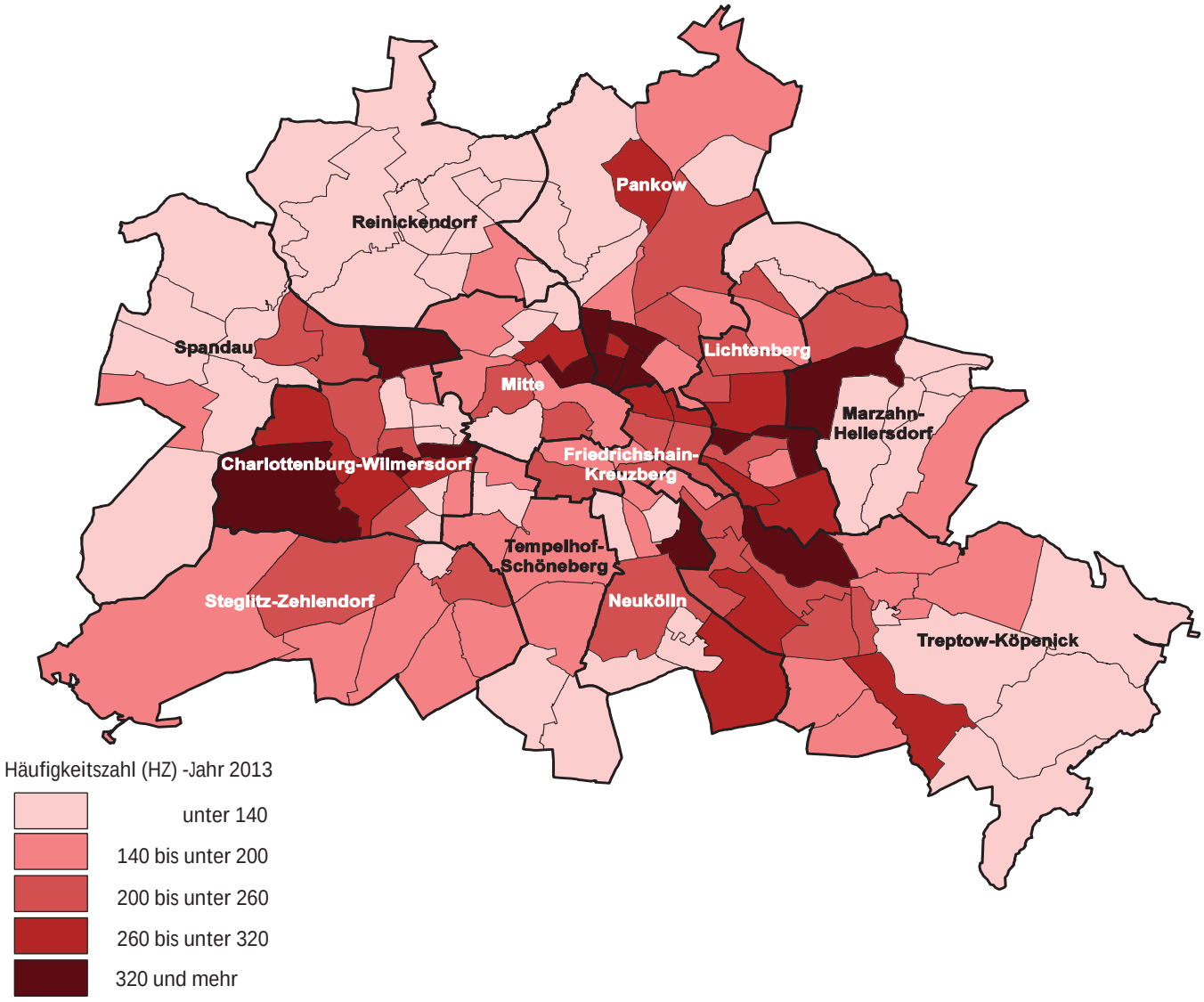

Diebstahl von Kraftwagen (PKS-Schlüssel 3**1**, 4**1**)

Bezirk	Jahr 2012		Jahr 2013		Zu-/Abnahme			
	erfasste Fälle	HZ	erfasste Fälle	HZ	Fälle absolut	Fälle in %	HZ absolut	HZ in %
Mitte	620	185	638	186	18	2,9	1	0,5
Friedrichshain-Kreuzberg	436	163	602	222	166	38,1	59	36,2
Pankow	770	210	862	231	92	11,9	21	10,0
Charlottenburg-Wilmersdorf	707	223	720	224	13	1,8	1	0,4
Spandau	253	114	303	135	50	19,8	21	18,4
Steglitz-Zehlendorf	466	158	545	184	79	17,0	26	16,5
Tempelhof-Schöneberg	504	154	506	154	2	0,4	-	-
Neukölln	394	125	558	174	164	41,6	49	39,2
Treptow-Köpenick	317	131	500	204	183	57,7	73	55,7
Marzahn-Hellersdorf	451	180	508	201	57	12,6	21	11,7
Lichtenberg	445	172	619	236	174	39,1	64	37,2
Reinickendorf	369	150	267	107	- 102	- 27,6	- 43	- 28,7
Berlin, nicht zuzuordnen	28		31					
Berlin -Gesamt-	**5 760**	**171**	**6 659**	**196**	**899**	**15,6**	**25**	**14,5**

Bezirk Berlin Mitte

Diebstahl von Kraftwagen (Häufigkeitszahl)

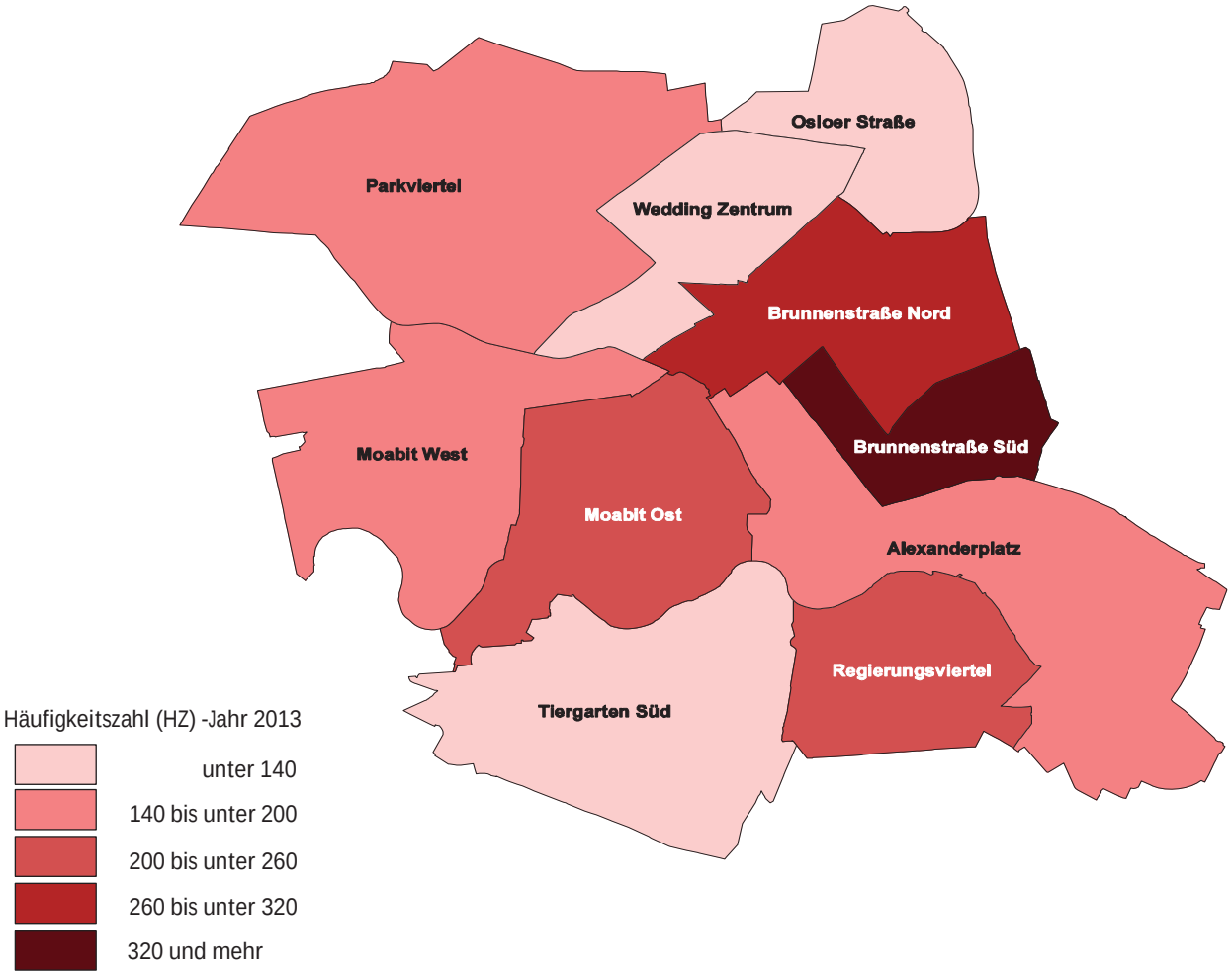

Diebstahl von Kraftwagen (PKS-Schlüssel 3**1**, 4**1**)

Bezirksregion	Jahr 2012		Jahr 2013		Zu-/Abnahme			
	erfasste Fälle	HZ	erfasste Fälle	HZ	Fälle absolut	Fälle in %	HZ absolut	HZ in %
Tiergarten Süd.....	18	143	17	131	- 1	x	- 12	(- 8,4)
Regierungsviertel.....	10	109	23	247	13	x	138	(126,6)
Alexanderplatz.....	81	172	85	177	4	x	5	(2,9)
Brunnenstraße Süd.....	86	336	101	380	15	x	44	(13,1)
Moabit West.....	94	224	76	178	- 18	x	- 46	(-20,5)
Moabit Ost.....	63	181	82	232	19	x	51	(28,2)
Osloer Straße.....	52	148	26	72	- 26	x	- 76	(-51,4)
Brunnenstraße Nord.....	76	215	102	285	26	x	70	(32,6)
Parkviertel.....	77	186	74	175	- 3	x	- 11	(-5,9)
Wedding Zentrum.....	57	108	48	89	- 9	x	- 19	(-17,6)
nicht zuzuordnen.....	6	-	4	-				

Bezirk Berlin Friedrichshain-Kreuzberg

Diebstahl von Kraftwagen (Häufigkeitszahl)

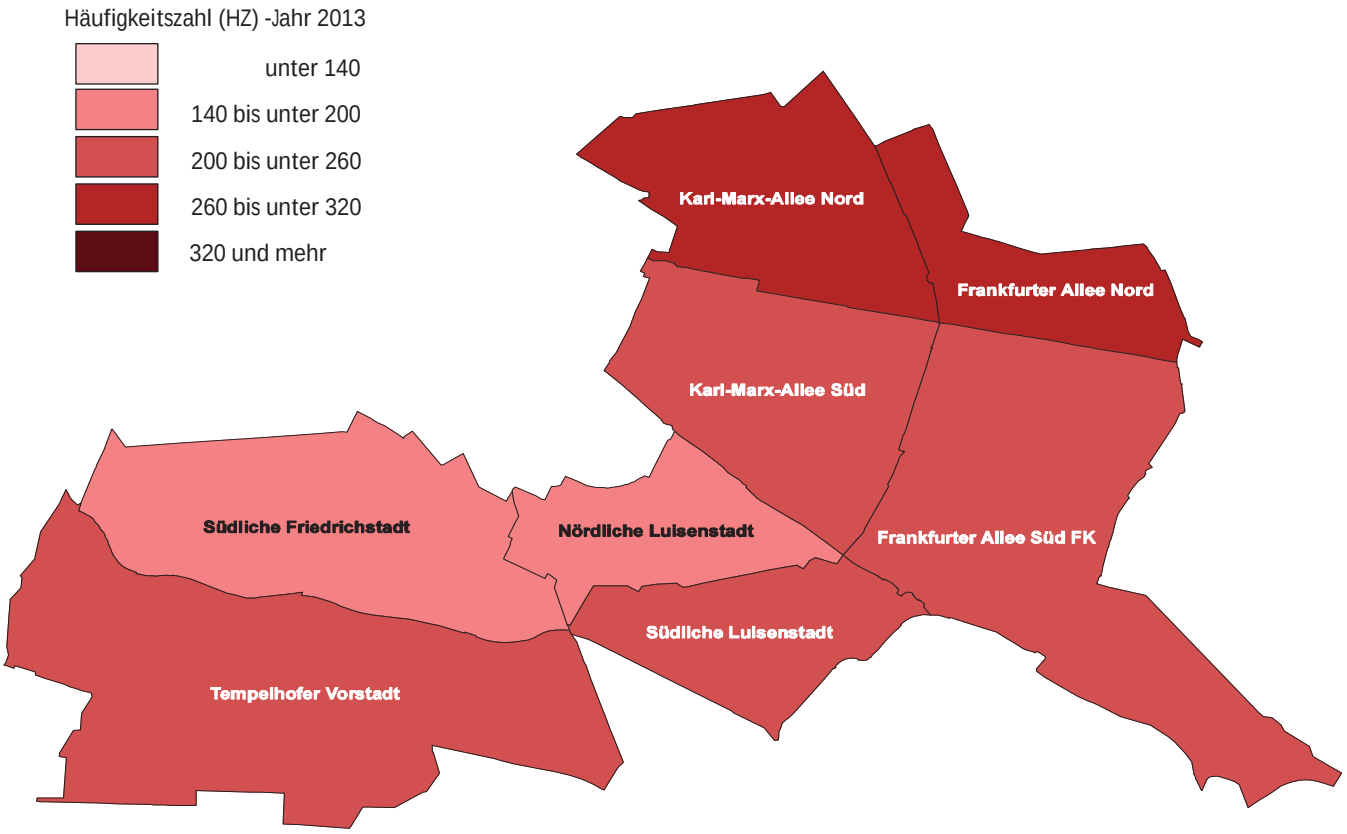

Diebstahl von Kraftwagen (PKS-Schlüssel 3**1**, 4**1**)

Bezirksregion	Jahr 2012		Jahr 2013		Zu-/Abnahme			
	erfasste Fälle	HZ	erfasste Fälle	HZ	Fälle		HZ	
					absolut	in %	absolut	in %
Südliche Friedrichstadt.....	52	133	57	144	5	x	11	(8,3)
Tempelhofer Vorstadt.....	90	148	142	229	52	x	81	(54,7)
Nördliche Luisenstadt.....	24	107	38	169	14	x	62	(57,9)
Südliche Luisenstadt.....	35	134	66	250	31	x	116	(86,6)
Karl-Marx-Allee Nord.....	71	319	62	276	- 9	x	- 43	(- 13,5)
Karl-Marx-Allee Süd.....	46	201	53	226	7	x	25	(12,4)
Frankfurter Allee Nord.....	55	202	82	297	27	x	95	(47,0)
Frankfurter Allee Süd FK.....	62	134	96	203	34	x	69	(51,5)
nicht zuzuordnen.....	1		6					

Bezirk Berlin Pankow

Diebstahl von Kraftwagen (Häufigkeitszahl)

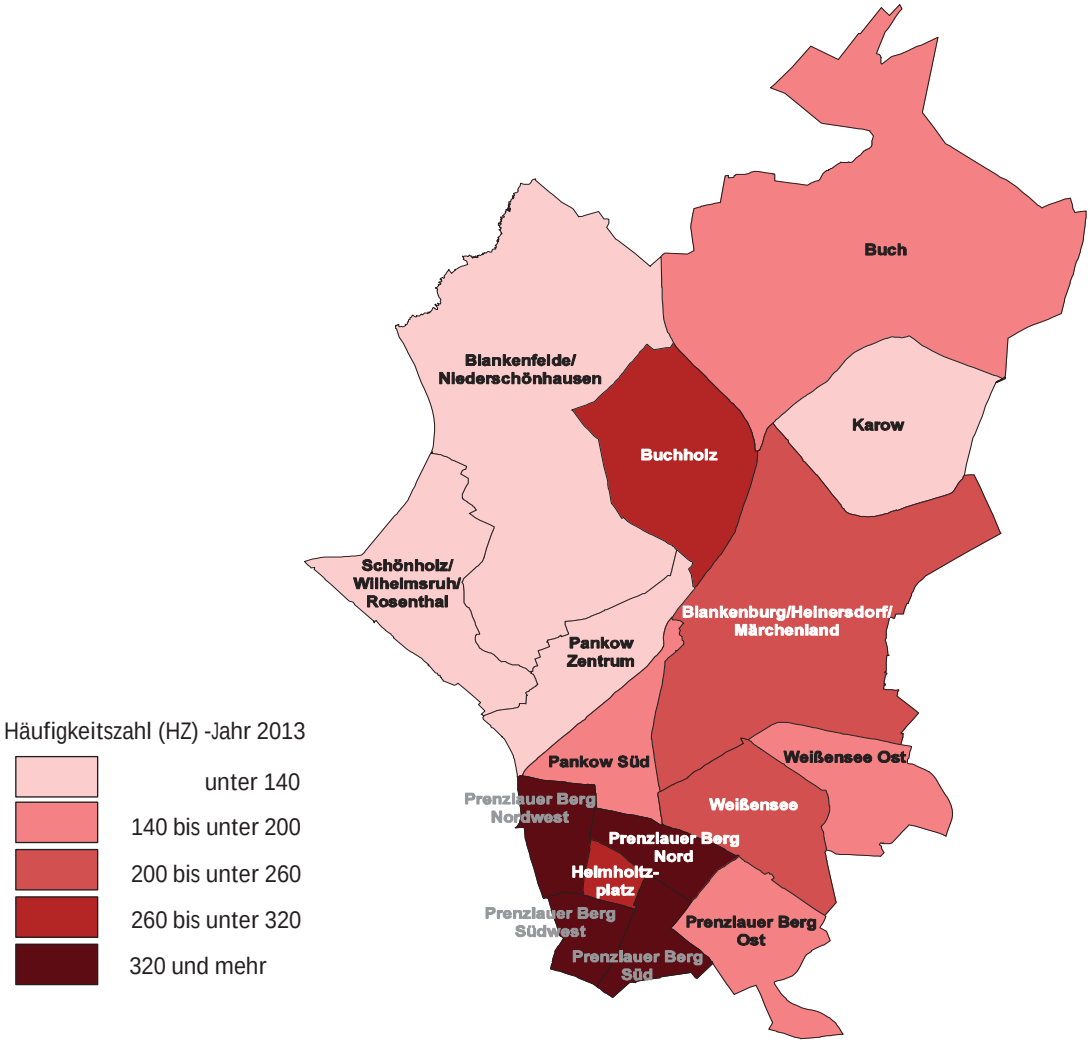

Diebstahl von Kraftwagen (PKS-Schlüssel 3**1**, 4**1**)

Bezirksregion	Jahr 2012		Jahr 2013		Zu-/Abnahme			
	erfasste Fälle	HZ	erfasste Fälle	HZ	Fälle absolut	Fälle in %	HZ absolut	HZ in %
Buch	32	245	21	155	- 11	x	- 90	(- 36,7)
Blankenfelde/Niederschönhausen	37	146	35	135	- 2	x	- 11	(- 7,5)
Buchholz	21	125	47	277	26	x	152	(121,6)
Karow	11	59	8	43	- 3	x	- 16	x
Blankenburg/Heinersdorf	14	99	34	240	20	x	141	x
Pankow Süd	56	176	55	169	- 1	x	- 7	(- 4,0)
Schönholz/Wilhelmsruh/Rosenthal	17	99	13	76	- 4	x	- 23	x
Pankow Zentrum	60	185	45	135	- 15	x	- 50	(- 27,0)
Weißensee	46	140	68	202	22	x	62	(44,3)
Weißensee Ost	20	133	22	145	2	x	12	(9,0)
Prenzlauer Berg Nordwest	95	402	94	388	- 1	x	- 14	(- 3,5)
Prenzlauer Berg Nord	86	333	88	337	2	x	4	(1,2)
Helmholtzplatz	41	193	57	263	16	x	70	(36,3)
Prenzlauer Berg Ost	57	235	49	198	- 8	x	- 37	(- 15,7)
Prenzlauer Berg Südwest	52	215	87	351	35	x	136	(63,3)
Prenzlauer Berg Süd	116	377	131	421	15	12,9	44	11,7
nicht zuzuordnen	9		8					

Bezirk Berlin Charlottenburg-Wilmersdorf

Diebstahl von Kraftwagen (Häufigkeitszahl)

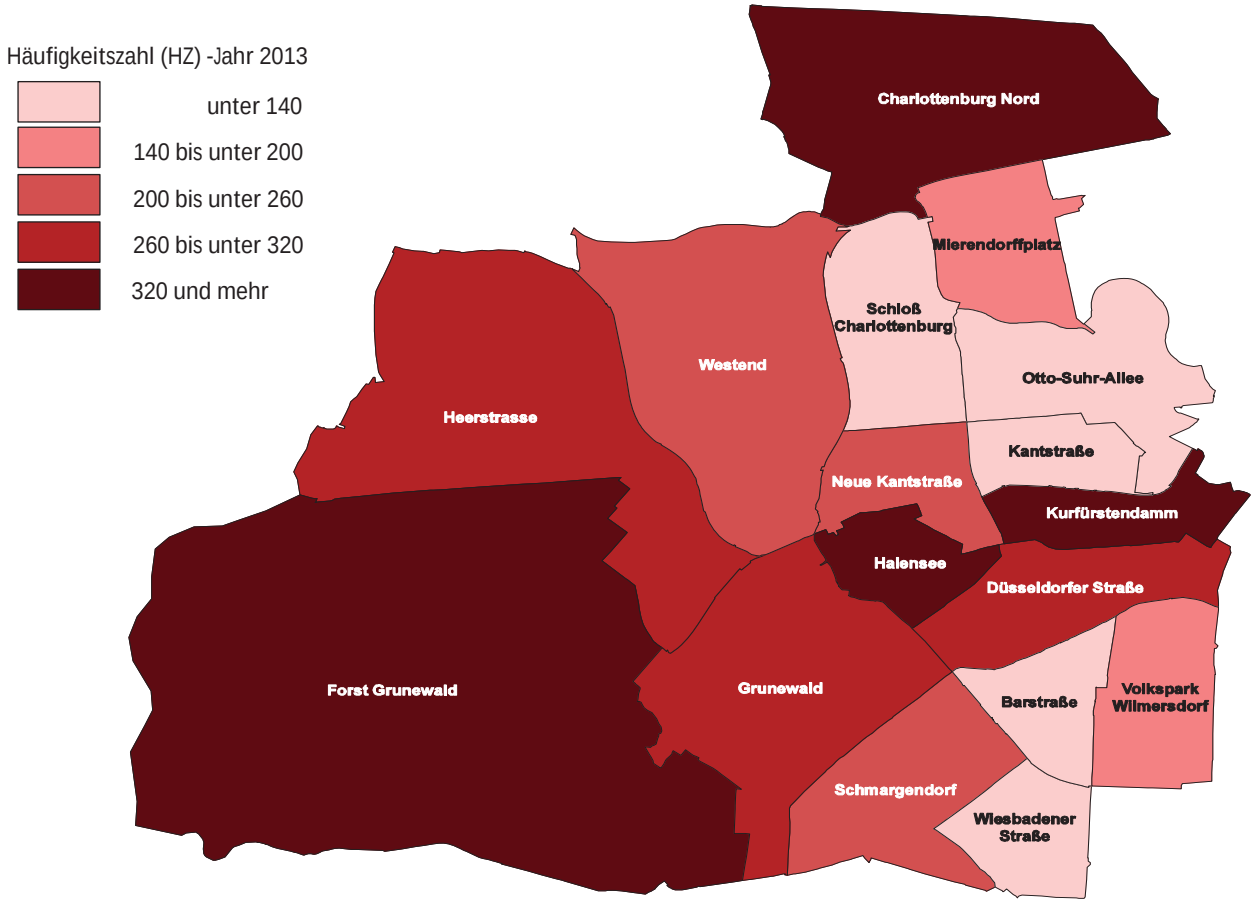

Diebstahl von Kraftwagen (PKS-Schlüssel 3**1**, 4**1**)

Bezirksregion	Jahr 2012		Jahr 2013		Zu-/Abnahme			
	erfasste Fälle	HZ	erfasste Fälle	HZ	Fälle absolut	Fälle in %	HZ absolut	HZ in %
Charlottenburg Nord.....	70	387	71	384	1	x	- 3	(- 0,8)
Heerstraße.....	37	296	34	270	- 3	x	- 26	(- 8,8)
Westend.....	57	218	64	240	7	x	22	(10,1)
Schloß Charlottenburg.....	31	134	29	124	- 2	x	- 10	(- 7,5)
Mierendorffplatz.....	31	218	21	144	- 10	x	- 74	(- 33,9)
Otto-Suhr-Allee.....	37	145	27	105	- 10	x	- 40	(- 27,6)
Neue Kantstraße.....	65	283	59	255	- 6	x	- 28	(- 9,9)
Kantstraße.....	24	117	20	97	- 4	x	- 20	(- 17,1)
Kurfürstendamm.....	54	371	60	411	6	x	40	(10,8)
Halensee.....	42	296	64	444	22	x	148	(50,0)
Grunewald.....	32	179	53	291	21	x	112	(62,6)
Schmargendorf.....	31	224	30	216	- 1	x	- 8	(- 3,6)
Wiesbadener Straße.....	30	166	24	133	- 6	x	- 33	(- 19,9)
Düsseldorfer Straße.....	68	232	83	279	15	x	47	(20,3)
Barstraße.....	23	170	15	111	- 8	x	- 59	(- 34,7)
Volkspark Wilmersdorf.....	67	207	61	186	- 6	x	- 21	(- 10,1)
Forst Grunewald.....	1		2		1	x		
nicht zuzuordnen.....	7		3					

Bezirk Berlin Spandau

Diebstahl von Kraftwagen (Häufigkeitszahl)

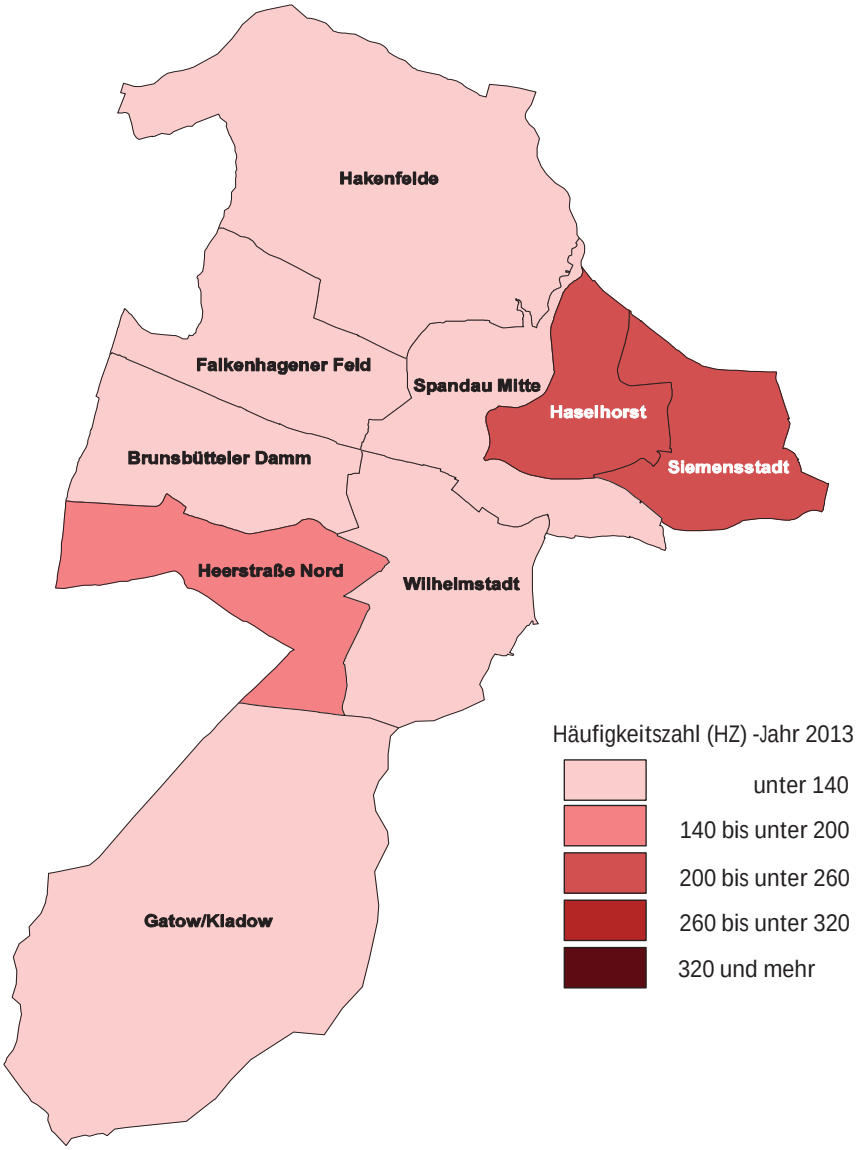

Diebstahl von Kraftwagen (PKS-Schlüssel 3**1**, 4**1**)

Bezirksregion	Jahr 2012		Jahr 2013		Zu-/Abnahme			
	erfasste Fälle	HZ	erfasste Fälle	HZ	Fälle		HZ	
					absolut	in %	absolut	in %
Hakenfelde.....	20	88	25	110	5	x	22	x
Falkenhagener Feld.....	31	79	35	89	4	x	10	x
Spandau Mitte.....	30	91	41	122	11	x	31	x
Brunsbütteler Damm.....	27	117	32	138	5	x	21	(17,9)
Heerstraße Nord.....	36	135	51	190	15	x	55	(40,7)
Wilhelmstadt.....	18	53	45	131	27	x	78	x
Haselhorst.....	36	261	30	208	- 6	x	- 53	(- 20,3)
Siemensstadt.....	30	258	29	242	- 1	x	- 16	(- 6,2)
Gatow/Kladow.....	24	135	11	61	- 13	x	- 74	(- 54,8)
nicht zuzuordnen.....	1		4					

Bezirk Berlin Steglitz-Zehlendorf

Diebstahl von Kraftwagen (Häufigkeitszahl)

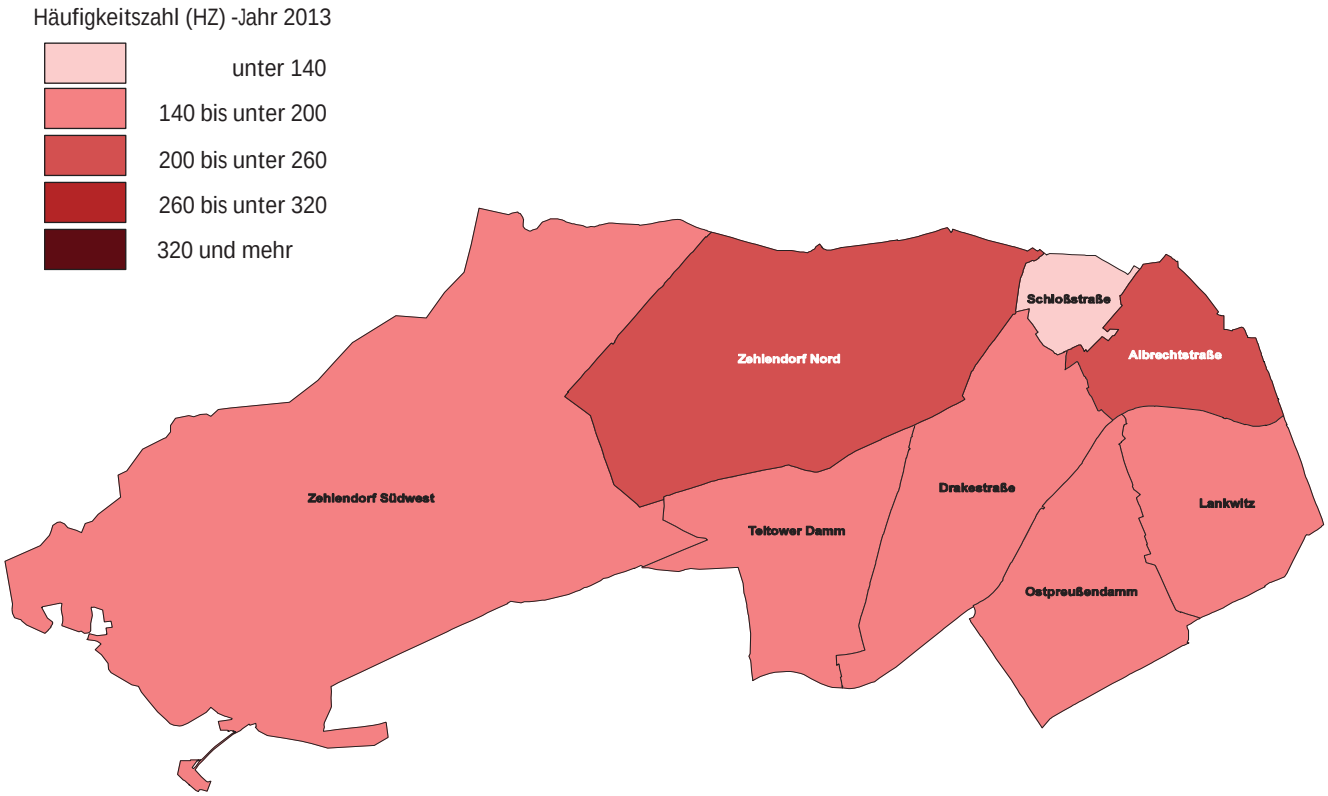

Diebstahl von Kraftwagen (PKS-Schlüssel 3**1**, 4**1**)

Bezirksregion	Jahr 2012		Jahr 2013		Zu-/Abnahme			
	erfasste Fälle	HZ	erfasste Fälle	HZ	Fälle absolut	Fälle in %	HZ absolut	HZ in %
Schloßstraße.....	29	136	29	134		x	- 2	(- 1,5)
Albrechtstraße.....	88	171	112	216	24	x	45	(26,3)
Lankwitz.....	45	109	61	146	16	x	37	(33,9)
Ostpreußendamm.....	53	153	61	174	8	x	21	(13,7)
Teltower Damm.....	36	110	57	174	21	x	64	(58,2)
Drakestraße.....	90	197	85	183	- 5	x	- 14	(- 7,1)
Zehlendorf Südwest.....	59	231	49	192	- 10	x	- 39	(- 16,9)
Zehlendorf Nord.....	62	149	88	212	26	x	63	(42,3)
nicht zuzuordnen.....	4		3					

Bezirk Berlin Tempelhof-Schöneberg

Diebstahl von Kraftwagen (Häufigkeitszahl)

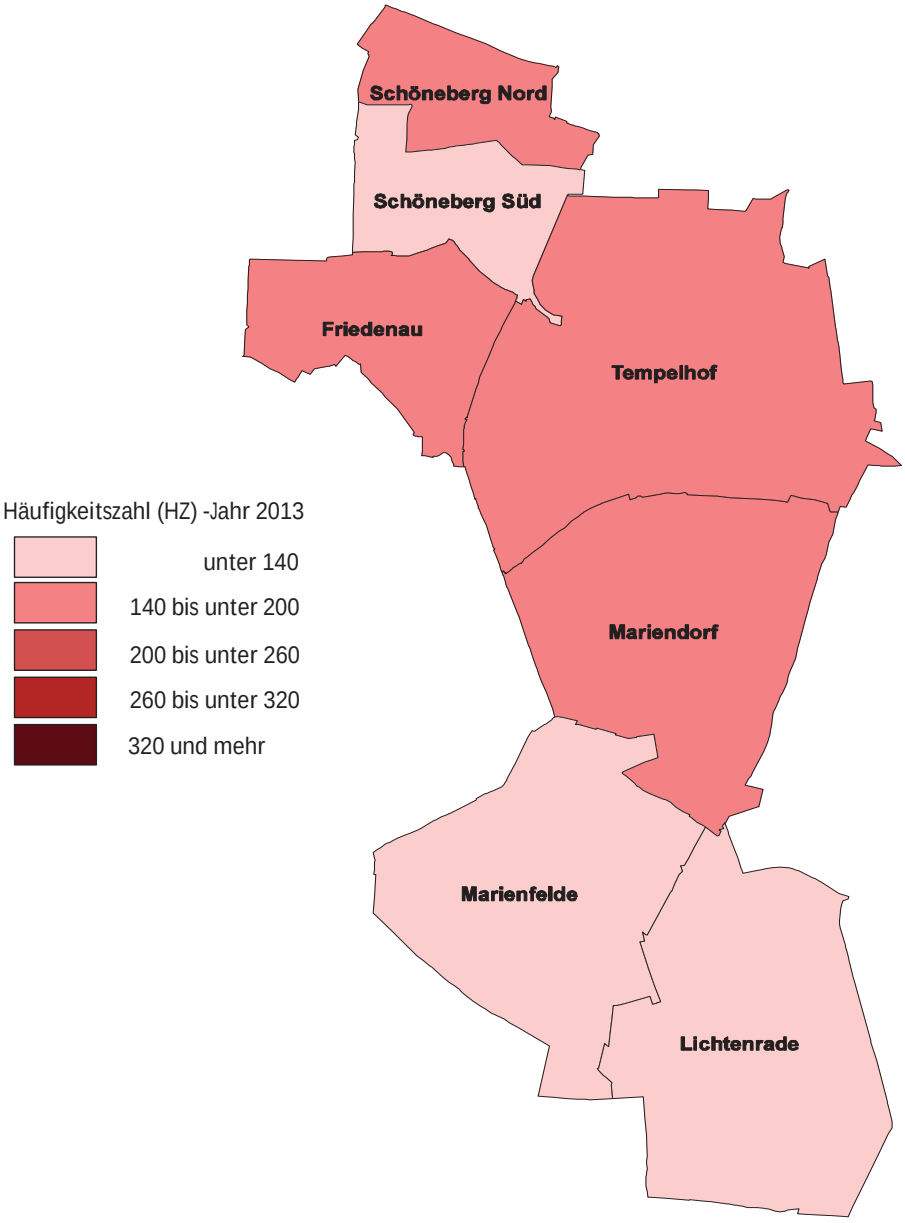

Diebstahl von Kraftwagen (PKS-Schlüssel 3**1**, 4**1**)

Bezirksregion	Jahr 2012		Jahr 2013		Zu-/Abnahme			
	erfasste Fälle	HZ	erfasste Fälle	HZ	Fälle		HZ	
					absolut	in %	absolut	in %
Schöneberg Nord.....	53	113	85	181	32	x	68	(60,2)
Schöneberg Süd.....	62	130	56	117	- 6	x	- 13	(- 10,0)
Friedenau.....	66	150	79	178	13	x	28	(18,7)
Tempelhof.....	122	207	109	182	- 13	- 10,7	- 25	- 12,1
Mariendorf.....	74	149	91	182	17	x	33	(22,1)
Marienfelde.....	62	204	35	115	- 27	x	- 89	(- 43,6)
Lichtenrade.....	63	127	51	103	- 12	x	- 24	(- 18,9)
nicht zuzuordnen.....	2							

Bezirk Berlin Neukölln

Diebstahl von Kraftwagen (Häufigkeitszahl)

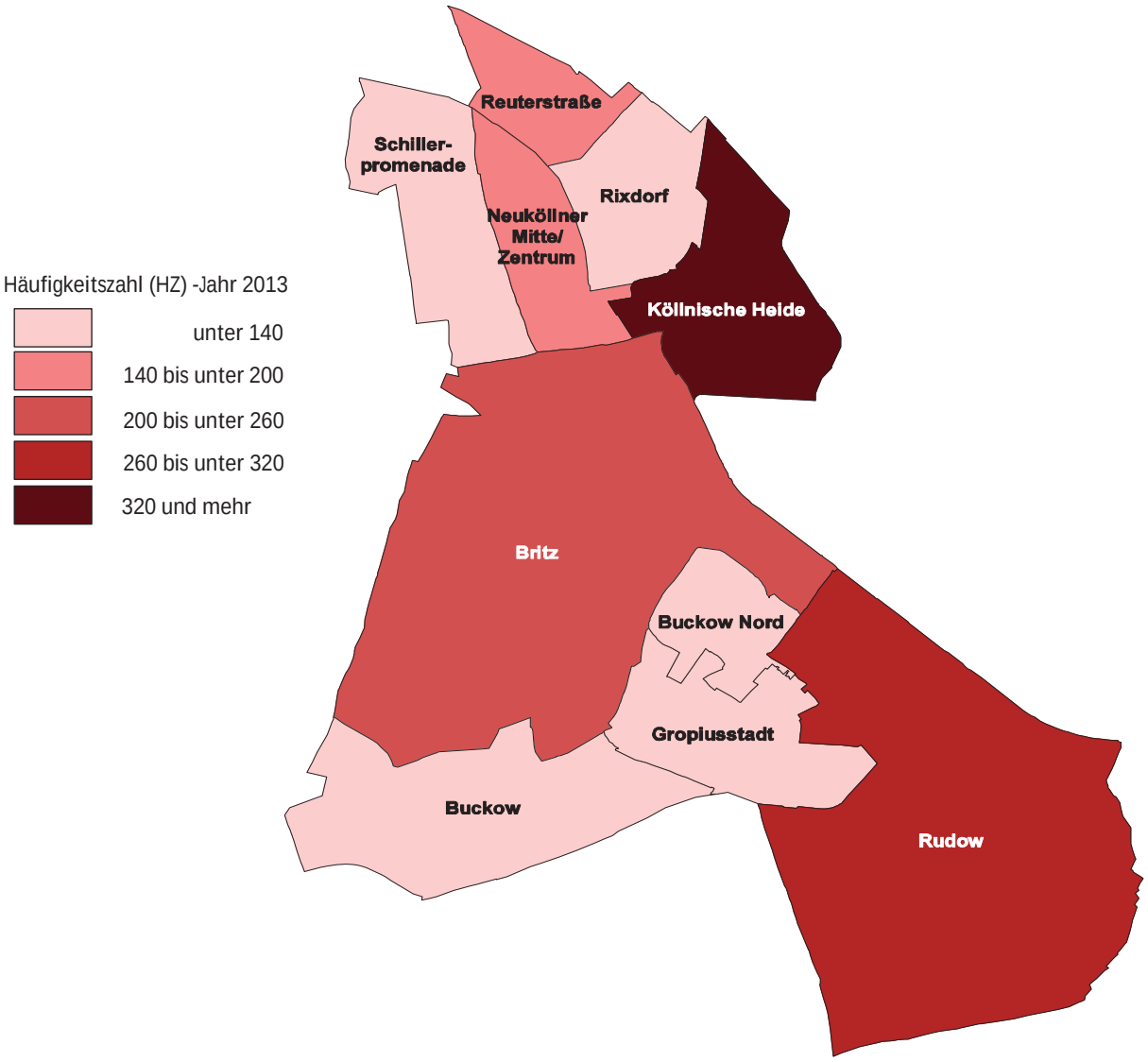

Diebstahl von Kraftwagen (PKS-Schlüssel 3**1**, 4**1**)

Bezirksregion	Jahr 2012		Jahr 2013		Zu-/Abnahme			
	erfasste Fälle	HZ	erfasste Fälle	HZ	Fälle		HZ	
					absolut	in %	absolut	in %
Schillerpromenade.....	27	87	40	127	13	x	40	x
Neuköllner Mitte/Zentrum.....	41	111	58	154	17	x	43	(38,7)
Reuterstraße.....	48	124	65	164	17	x	40	(32,3)
Rixdorf.....	38	98	50	126	12	x	28	x
Köllnische Heide.....	49	332	54	359	5	x	27	(8,1)
Britz.....	71	175	99	241	28	x	66	(37,7)
Buckow.....	24	87	23	83	- 1	x	- 4	x
Gropiusstadt.....	25	69	44	121	19	x	52	x
Buckow Nord.....	11	118	12	128	1	x	10	(8,5)
Rudow.....	58	138	111	264	53	x	126	(91,3)
nicht zuzuordnen.....	2		2					

Bezirk Berlin Treptow-Köpenick

Diebstahl von Kraftwagen (Häufigkeitszahl)

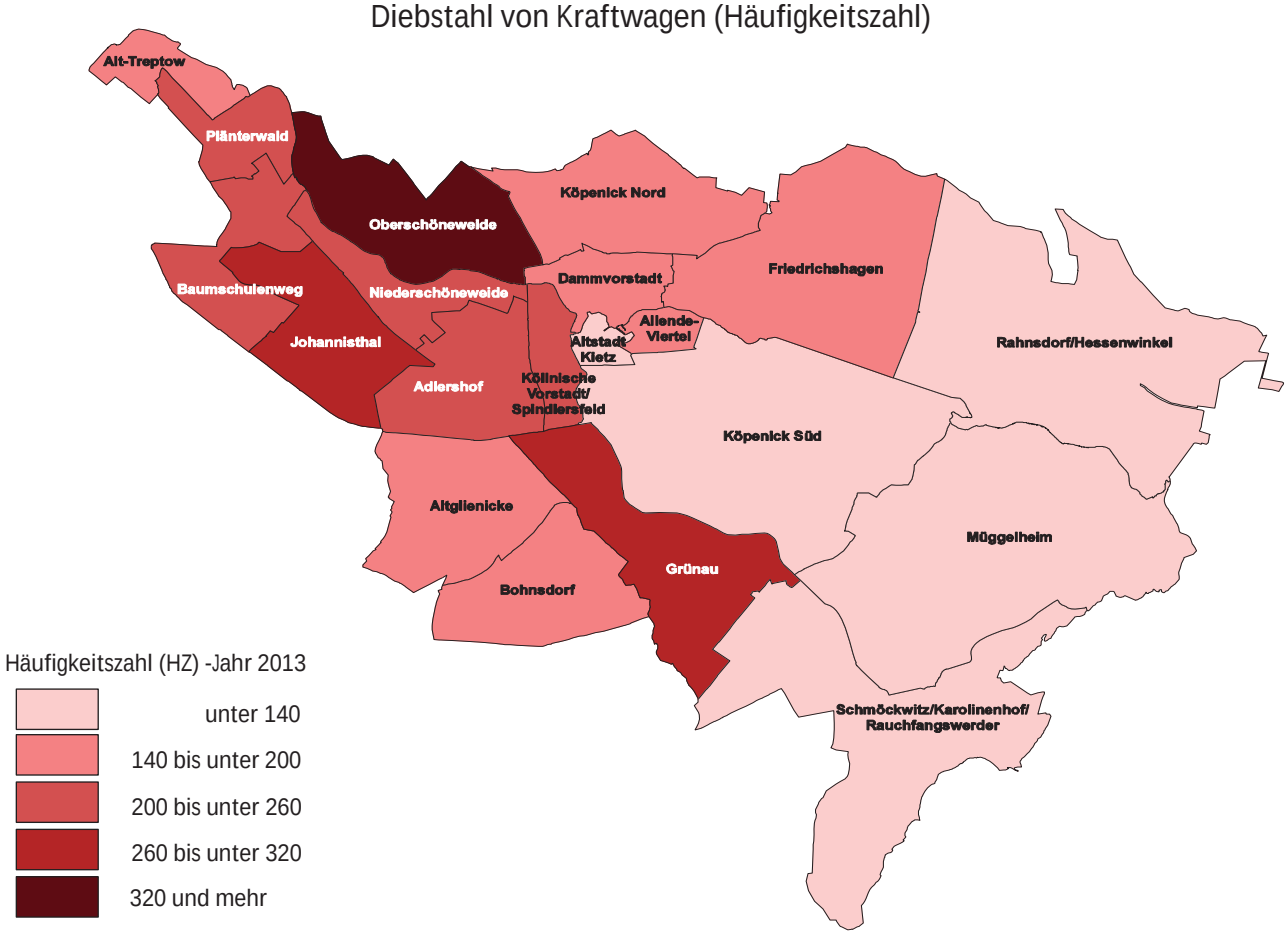

Diebstahl von Kraftwagen (PKS-Schlüssel 3**1**, 4**1**)

Bezirksregion	Jahr 2012		Jahr 2013		Zu-/Abnahme			
	erfasste Fälle	HZ	erfasste Fälle	HZ	Fälle		HZ	
					absolut	in %	absolut	in %
Alt-Treptow	15	137	21	189	6	x	52	(38,0)
Plänterwald	20	185	27	249	7	x	64	(34,6)
Baumschulenweg	25	145	35	201	10	x	56	(38,6)
Johannisthal	22	120	57	309	35	x	189	(157,5)
Oberschöneweide	42	219	69	350	27	x	131	(59,8)
Niederschöneweide	12	115	25	235	13	x	120	(104,3)
Adlershof	24	156	32	205	8	x	49	(31,4)
Kölln. Vorstadt/Spindlersf.	11	112	20	200	9	x	88	(78,6)
Altglienicke	34	133	47	182	13	x	49	(36,8)
Bohnsdorf	18	151	23	191	5	x	40	(26,5)
Grünau	4	74	15	268	11	x	194	x
Schmöckwitz/Karolinenhof	2	49	4	99	2	x	50	x
Köpenick Süd	18	115	20	129	2	x	14	(12,2)
Allende-Viertel	12	197	10	163	- 2	x	- 34	(- 17,3)
Altstadt Kietz	5	73	7	101	2	x	28	x
Müggelheim	7	108	6	92	- 1	x	- 16	(- 14,8)
Friedrichshagen	16	92	30	172	14	x	80	x
Rahnsdorf/Hessenwinkel	15	167	11	123	- 4	x	- 44	(- 26,3)
Dammvorstadt	9	96	16	168	7	x	72	x
Köpenick Nord	4	33	20	163	16	x	130	x
nicht zuzuordnen	2		5					

Bezirk Berlin Marzahn-Hellersdorf

Diebstahl von Kraftwagen (Häufigkeitszahl)

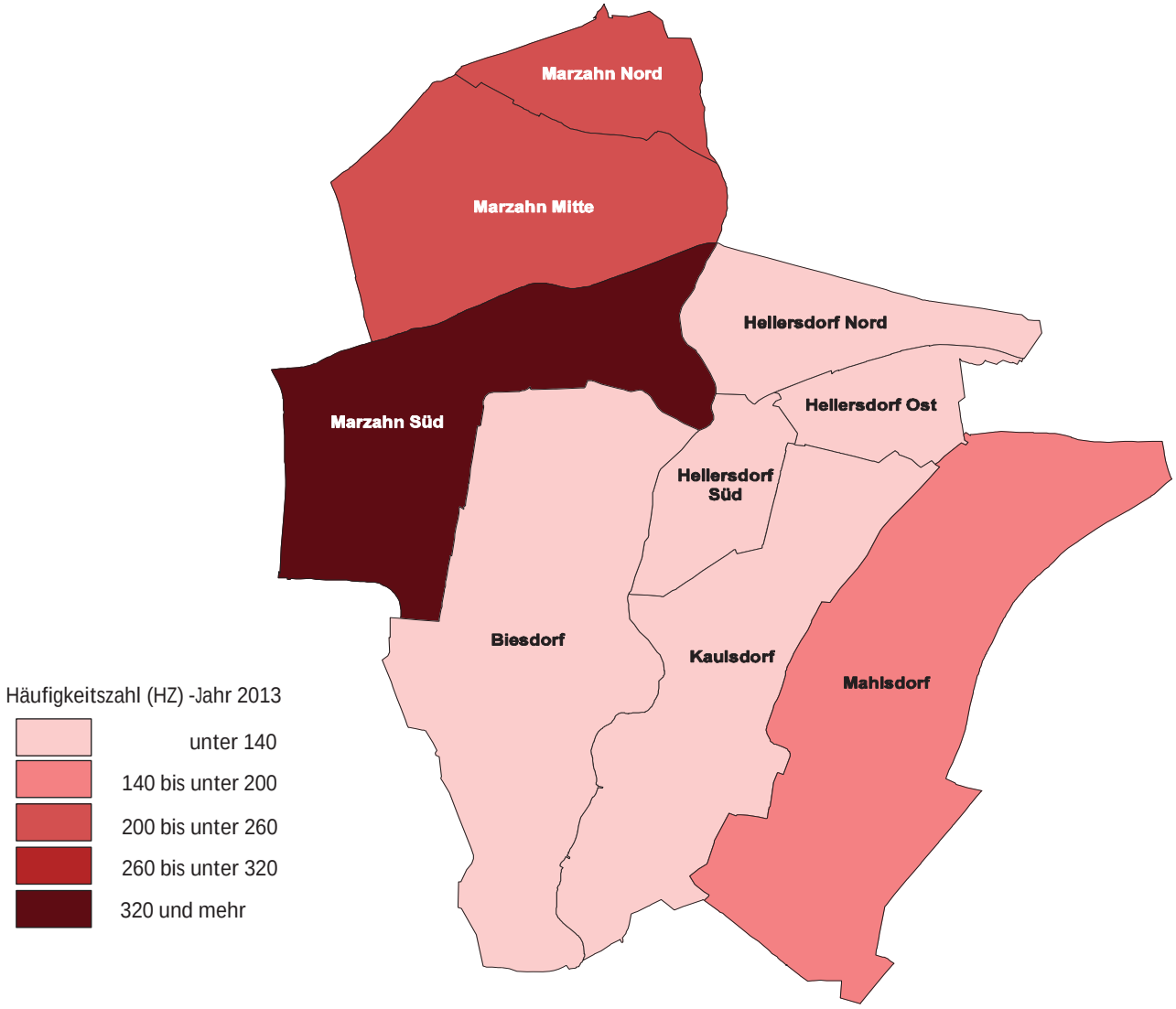

Diebstahl von Kraftwagen (PKS-Schlüssel 3**1**, 4**1**)

Bezirksregion	Jahr 2012		Jahr 2013		Zu-/Abnahme			
	erfasste Fälle	HZ	erfasste Fälle	HZ	Fälle		HZ	
					absolut	in %	absolut	in %
Marzahn Nord	34	150	52	227	18	x	77	(51,3)
Marzahn Mitte	104	230	103	226	- 1	- 1,0	- 4	- 1,7
Marzahn Süd	135	374	157	429	22	16,3	55	14,7
Hellersdorf Nord	46	140	45	135	- 1	x	- 5	(- 3,6)
Hellersdorf Ost	21	114	18	95	- 3	x	- 19	(- 16,7)
Hellersdorf Süd	35	144	32	131	- 3	x	- 13	(- 9,0)
Biesdorf	36	143	35	137	- 1	x	- 6	(- 4,2)
Kaulsdorf	17	91	16	86	- 1	x	- 5	x
Mahlsdorf	20	74	41	151	21	x	77	x
nicht zuzuordnen	3		9					

Bezirk Berlin Lichtenberg

Diebstahl von Kraftwagen (Häufigkeitszahl)

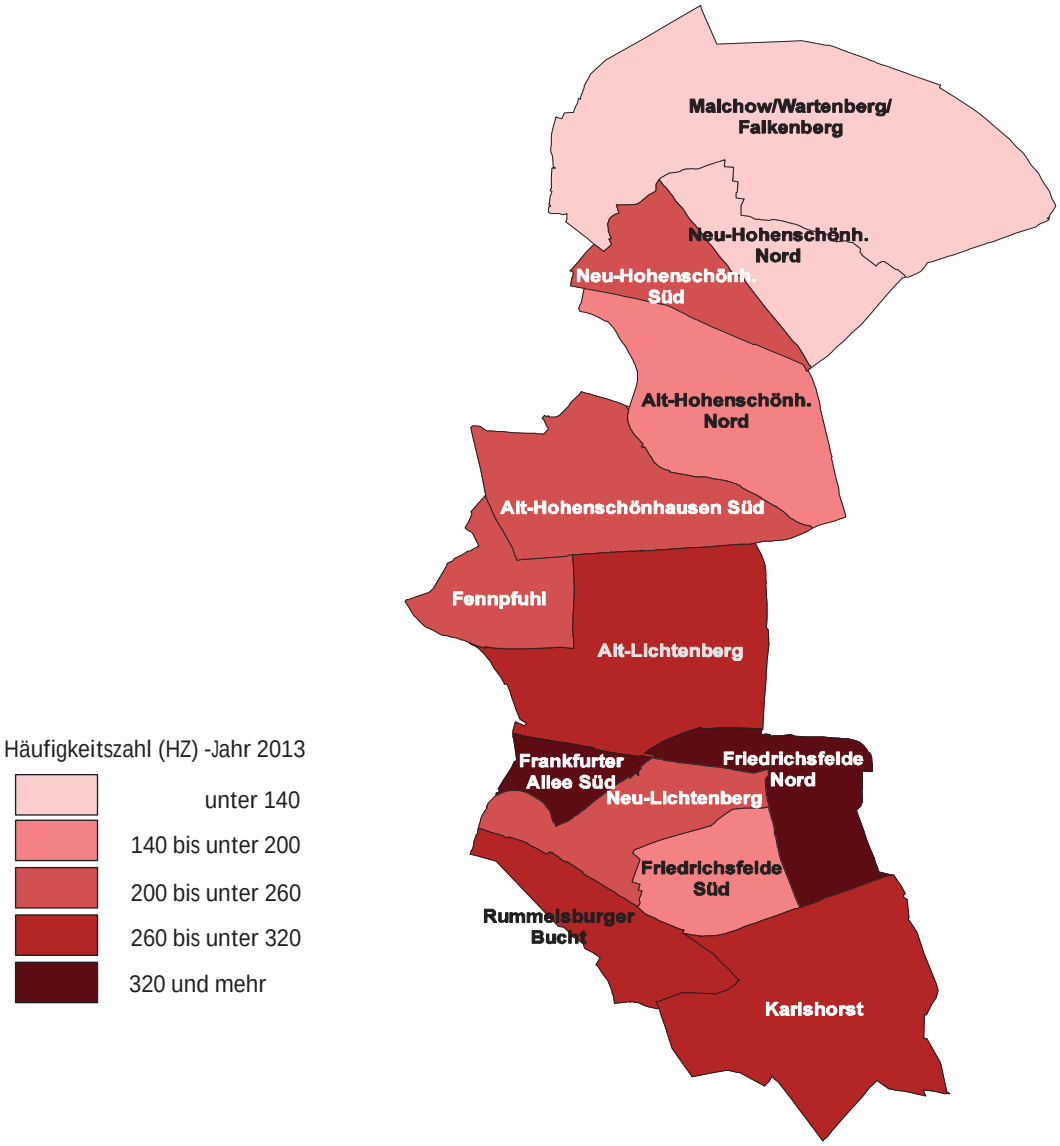

Diebstahl von Kraftwagen (PKS-Schlüssel 3**1**, 4**1**)

Bezirksregion	Jahr 2012		Jahr 2013		Zu-/Abnahme			
	erfasste Fälle	HZ	erfasste Fälle	HZ	Fälle absolut	Fälle in %	HZ absolut	HZ in %
Malchow/Warten-/Falkenberg.....	3	72	4	94	1	x	22	x
Neu-Hohenschönhausen Nord.....	30	109	27	98	- 3	x	- 11	(- 10,1)
Neu-Hohenschönhausen Süd.....	42	162	62	240	20	x	78	(48,1)
Alt-Hohenschönhausen Nord.....	18	134	24	178	6	x	44	(32,8)
Alt-Hohenschönhausen Süd.....	59	201	72	244	13	x	43	(21,4)
Fennpfuhl.....	67	211	77	241	10	x	30	(14,2)
Alt-Lichtenberg.....	58	241	65	261	7	x	20	(8,3)
Frankfurter Allee Süd.....	24	248	35	349	11	x	101	(40,7)
Neu-Lichtenberg.....	53	180	72	240	19	x	60	(33,3)
Friedrichsfelde Nord.....	30	225	50	370	20	x	145	(64,4)
Friedrichsfelde Süd.....	41	170	49	199	8	x	29	(17,1)
Rummelsburger Bucht.....	4	123	9	271	5	x	148	(120,3)
Karlshorst.....	15	66	67	287	52	x	221	x
nicht zuzuordnen.....	1		6					

Bezirk Berlin Reinickendorf

Diebstahl von Kraftwagen (Häufigkeitszahl)

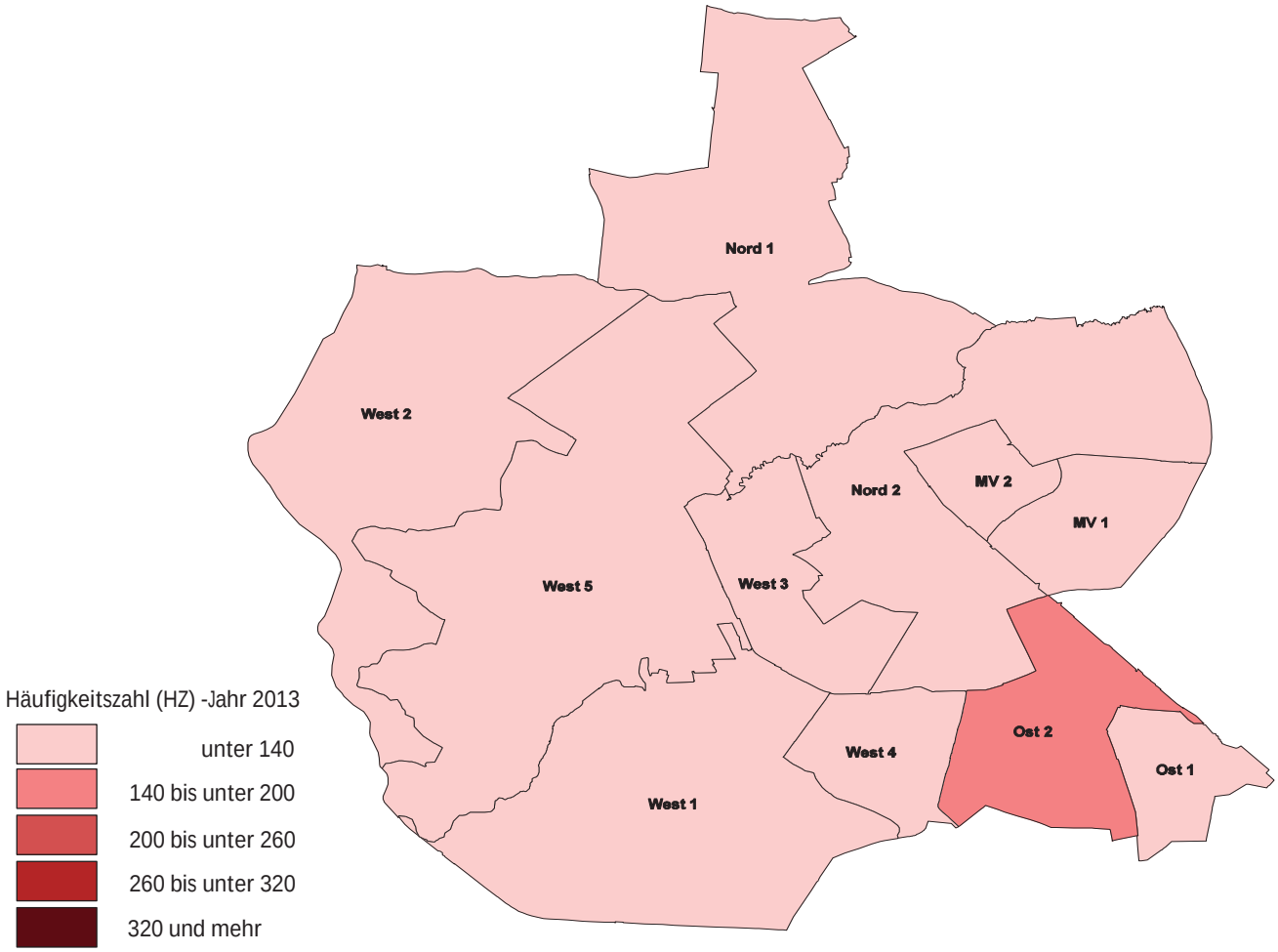

Diebstahl von Kraftwagen (PKS-Schlüssel 3**1**, 4**1**)

Bezirksregion	Jahr 2012		Jahr 2013		Zu-/Abnahme			
	erfasste Fälle	HZ	erfasste Fälle	HZ	Fälle		HZ	
					absolut	in %	absolut	in %
Ost 1	38	148	30	115	- 8	x	- 33	(- 22,3)
Ost 2	37	145	39	151	2	x	6	(4,1)
West 1	36	247	20	138	- 16	x	- 109	(- 44,1)
West 4	27	108	32	126	5	x	18	(16,7)
West 5	9	88	12	117	3	x	29	x
West 2	43	182	16	67	- 27	x	- 115	(- 63,2)
Nord 1	50	153	41	125	- 9	x	- 28	(- 18,3)
Nord 2	30	103	22	74	- 8	x	- 29	(- 28,2)
MV 1	65	184	37	102	- 28	x	- 82	(- 44,6)
MV 2	8	98	6	71	- 2	x	- 27	x
West 3	24	150	11	69	- 13	x	- 81	(- 54,0)
nicht zuzuordnen	2		1					

Berlin - Diebstahl an/aus Kraftfahrzeugen (Häufigkeitszahl)

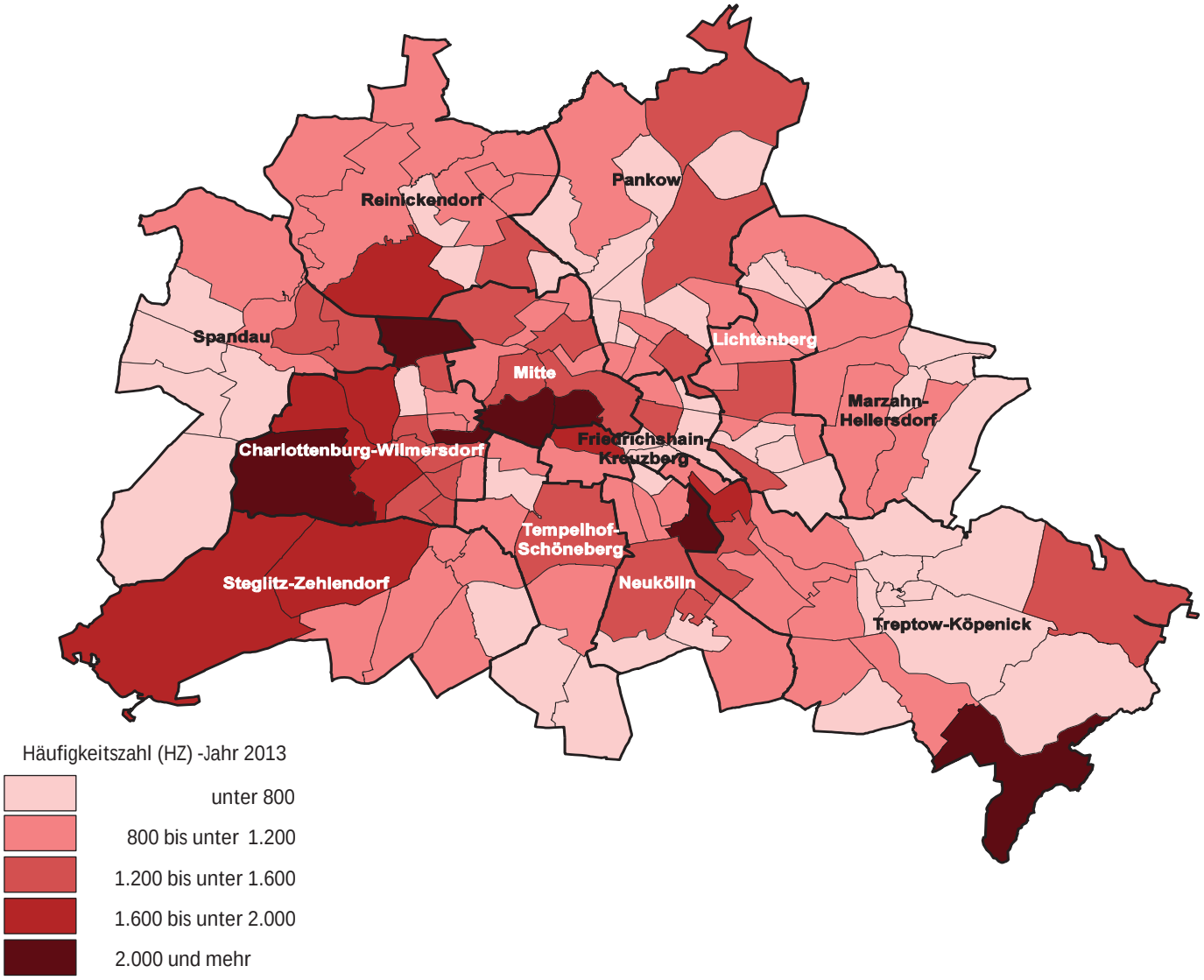

Diebstahl an/aus Kraftfahrzeugen (PKS-Schlüssel 350***, 450***)

Bezirk	Jahr 2012		Jahr 2013		Zu-/Abnahme			
	erfasste Fälle	HZ	erfasste Fälle	HZ	Fälle		HZ	
					absolut	in %	absolut	in %
Mitte	4 317	1 286	4 753	1 383	436	10,1	97	7,5
Friedrichshain-Kreuzberg	2 380	892	2 636	972	256	10,8	80	9,0
Pankow	2 553	695	3 138	840	585	22,9	145	20,9
Charlottenburg-Wilmersdorf	3 770	1 190	4 686	1 461	916	24,3	271	22,8
Spandau	1 470	664	1 650	735	180	12,2	71	10,7
Steglitz-Zehlendorf	2 376	808	3 275	1 105	899	37,8	297	36,8
Tempelhof-Schöneberg	2 973	908	3 253	988	280	9,4	80	8,8
Neukölln	2 872	910	3 332	1 040	460	16,0	130	14,3
Treptow-Köpenick	1 571	648	2 236	914	665	42,3	266	41,0
Marzahn-Hellersdorf	1 778	710	2 032	803	254	14,3	93	13,1
Lichtenberg	1 979	766	2 147	818	168	8,5	52	6,8
Reinickendorf	2 464	1 002	2 514	1 009	50	2,0	7	0,7
Berlin, nicht zuzuordnen	358		382					
Berlin -Gesamt-	**30 861**	**915**	**36 034**	**1 058**	**5 173**	**16,8**	**143**	**15,6**

Bezirk Berlin Mitte

Diebstahl an/aus Kraftfahrzeugen (Häufigkeitszahl)

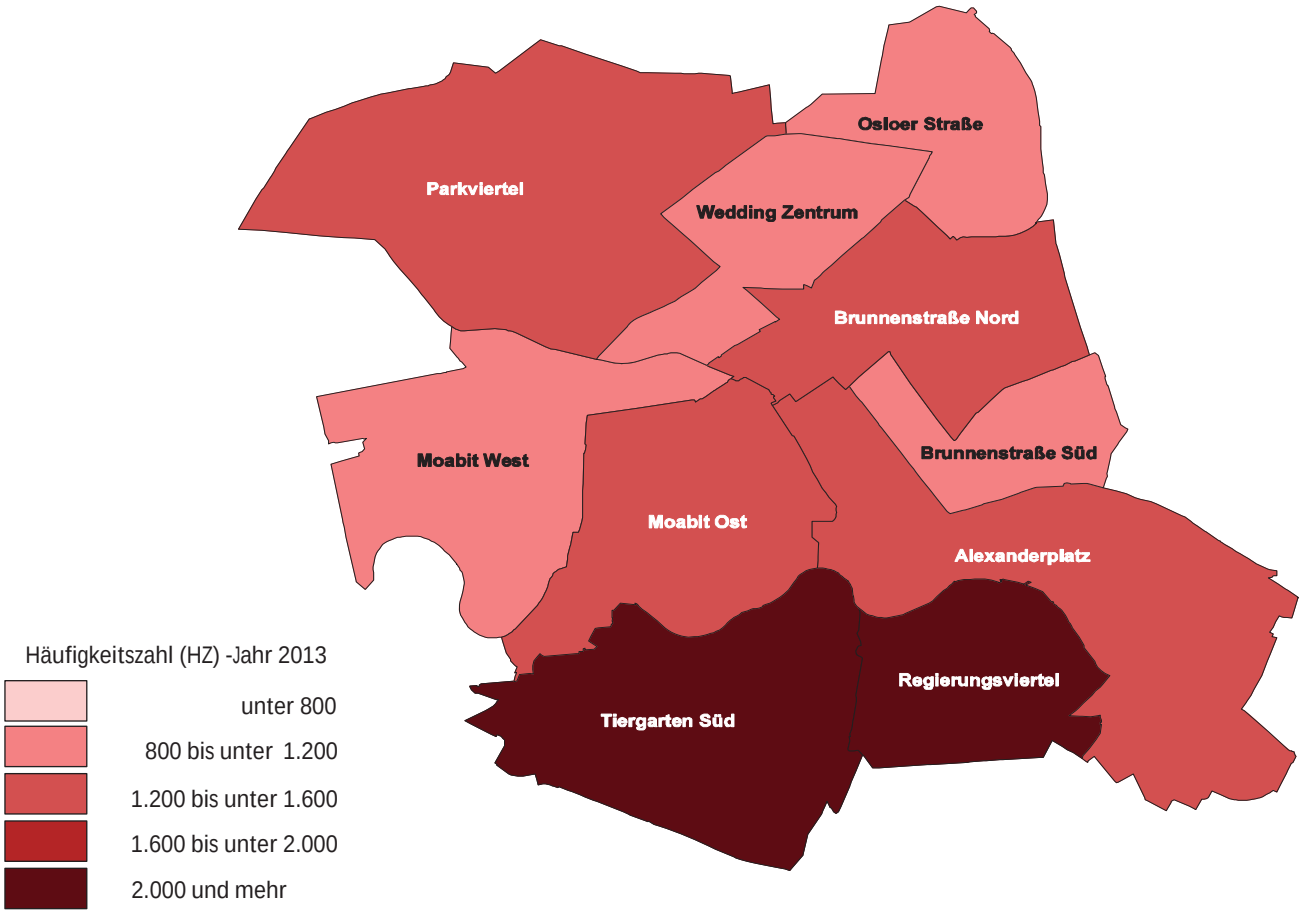

Diebstahl an/aus Kraftfahrzeugen (PKS-Schlüssel 350***, 450***)

Bezirksregion	Jahr 2012		Jahr 2013		Zu-/Abnahme			
	erfasste Fälle	HZ	erfasste Fälle	HZ	Fälle		HZ	
					absolut	in %	absolut	in %
Tiergarten Süd	328	2 603	392	3 013	64	19,5	410	15,8
Regierungsviertel	307	3 349	337	3 624	30	9,8	275	8,2
Alexanderplatz	792	1 678	760	1 579	- 32	- 4,0	- 99	- 5,9
Brunnenstraße Süd	192	751	244	919	52	27,1	168	22,4
Moabit West	410	979	463	1 083	53	12,9	104	10,6
Moabit Ost	353	1 013	446	1 263	93	26,3	250	24,7
Osloer Straße	429	1 224	378	1 044	- 51	- 11,9	- 180	- 14,7
Brunnenstraße Nord	473	1 340	521	1 454	48	10,1	114	8,5
Parkviertel	564	1 361	566	1 336	2	0,4	- 25	- 1,8
Wedding Zentrum	424	807	603	1 114	179	42,2	307	38,0
nicht zuzuordnen	45	-	43	-				

Bezirk Berlin Friedrichshain-Kreuzberg

Diebstahl an/aus Kraftfahrzeugen (Häufigkeitszahl)

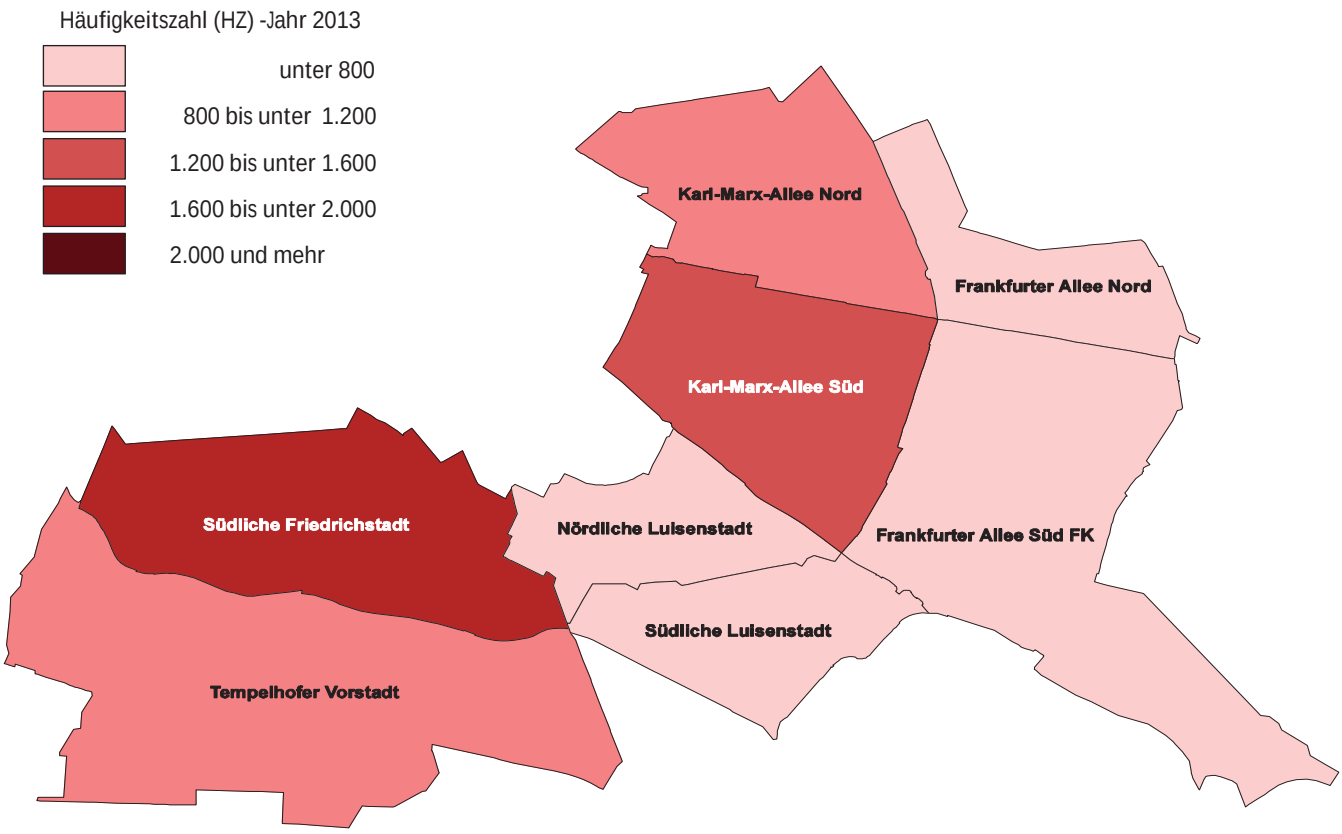

Diebstahl an/aus Kraftfahrzeugen (PKS-Schlüssel 350***, 450***)

Bezirksregion	Jahr 2012		Jahr 2013		Zu-/Abnahme			
	erfasste Fälle	HZ	erfasste Fälle	HZ	Fälle		HZ	
					absolut	in %	absolut	in %
Südliche Friedrichstadt.....	500	1 284	700	1 772	200	40,0	488	38,0
Tempelhofer Vorstadt.....	595	977	618	998	23	3,9	21	2,1
Nördliche Luisenstadt.....	186	833	165	732	- 21	- 11,3	- 101	- 12,1
Südliche Luisenstadt.....	226	866	169	639	- 57	- 25,2	- 227	- 26,2
Karl-Marx-Allee Nord.....	206	925	189	841	- 17	- 8,3	- 84	- 9,1
Karl-Marx-Allee Süd.....	242	1 055	304	1 298	62	25,6	243	23,0
Frankfurter Allee Nord.....	117	431	150	543	33	28,2	112	26,0
Frankfurter Allee Süd FK.....	291	630	333	705	42	14,4	75	11,9
nicht zuzuordnen.....	17		8					

Bezirk Berlin Pankow

Diebstahl an/aus Kraftfahrzeugen (Häufigkeitszahl)

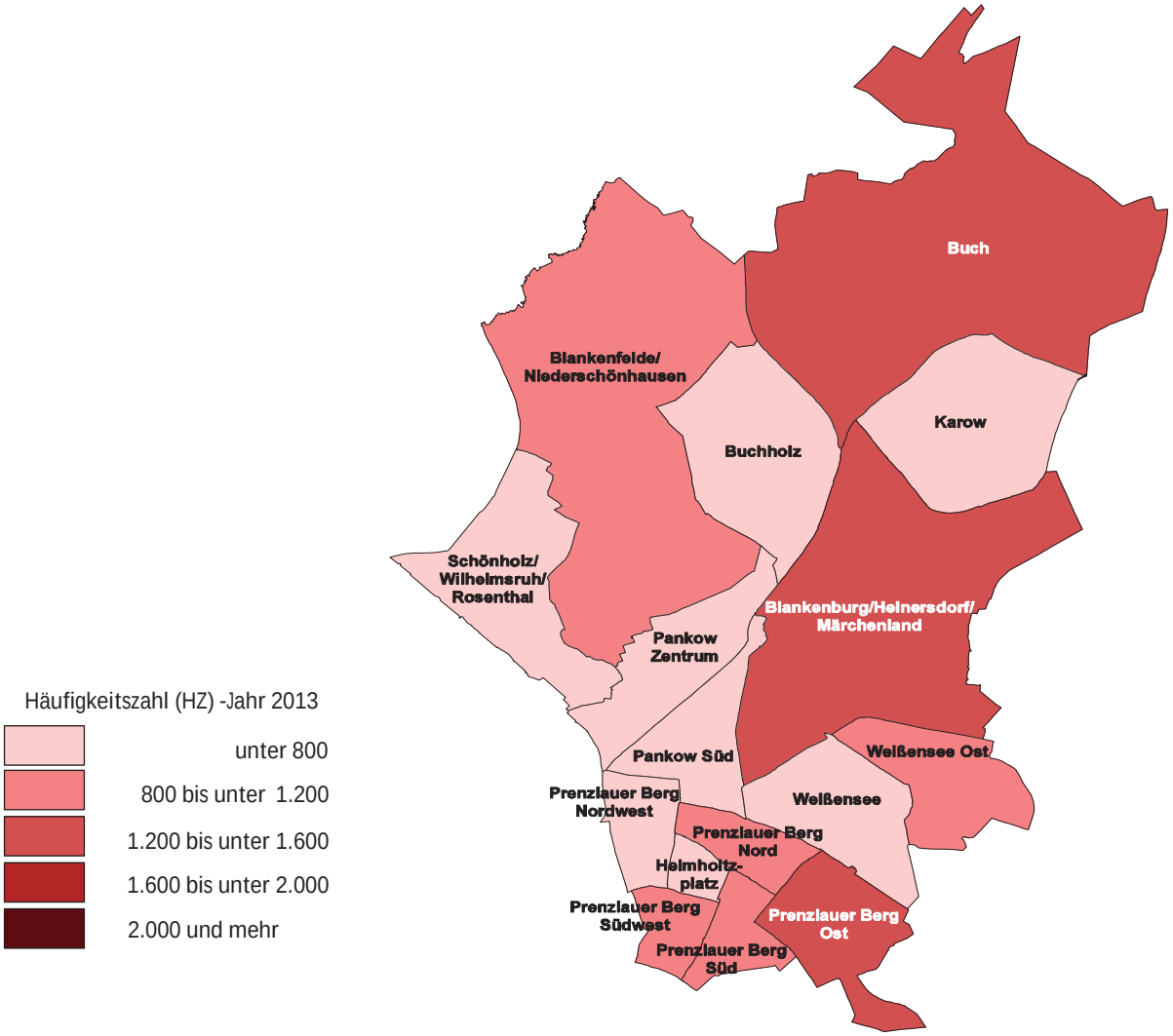

Diebstahl an/aus Kraftfahrzeugen (PKS-Schlüssel 350***, 450***)

Bezirksregion	Jahr 2012		Jahr 2013		Zu-/Abnahme			
	erfasste Fälle	HZ	erfasste Fälle	HZ	Fälle absolut	Fälle in %	HZ absolut	HZ in %
Buch	190	1 457	180	1 329	- 10	- 5,3	- 128	- 8,8
Blankenfelde/Niederschönhausen	179	707	274	1 054	95	53,1	347	49,1
Buchholz	69	411	74	436	5	x	25	(6,1)
Karow	85	455	102	548	17	x	93	(20,4)
Blankenburg/Heinersdorf	160	1 133	217	1 535	57	35,6	402	35,5
Pankow Süd	170	534	222	684	52	30,6	150	28,1
Schönholz/Wilhelmsruh/Rosenthal	138	806	131	763	- 7	- 5,1	- 43	- 5,3
Pankow Zentrum	220	678	254	762	34	15,5	84	12,4
Weißensee	192	583	225	669	33	17,2	86	14,8
Weißensee Ost	105	700	147	971	42	40,0	271	38,7
Prenzlauer Berg Nordwest	176	745	184	759	8	4,5	14	1,9
Prenzlauer Berg Nord	146	566	216	828	70	47,9	262	46,3
Helmholtzplatz	74	349	91	420	17	x	71	(20,3)
Prenzlauer Berg Ost	216	889	317	1 278	101	46,8	389	43,8
Prenzlauer Berg Südwest	223	920	218	879	- 5	- 2,2	- 41	- 4,5
Prenzlauer Berg Süd	186	604	256	822	70	37,6	218	36,1
nicht zuzuordnen	24		30					

Bezirk Berlin Charlottenburg-Wilmersdorf

Diebstahl an/aus Kraftfahrzeugen (Häufigkeitszahl)

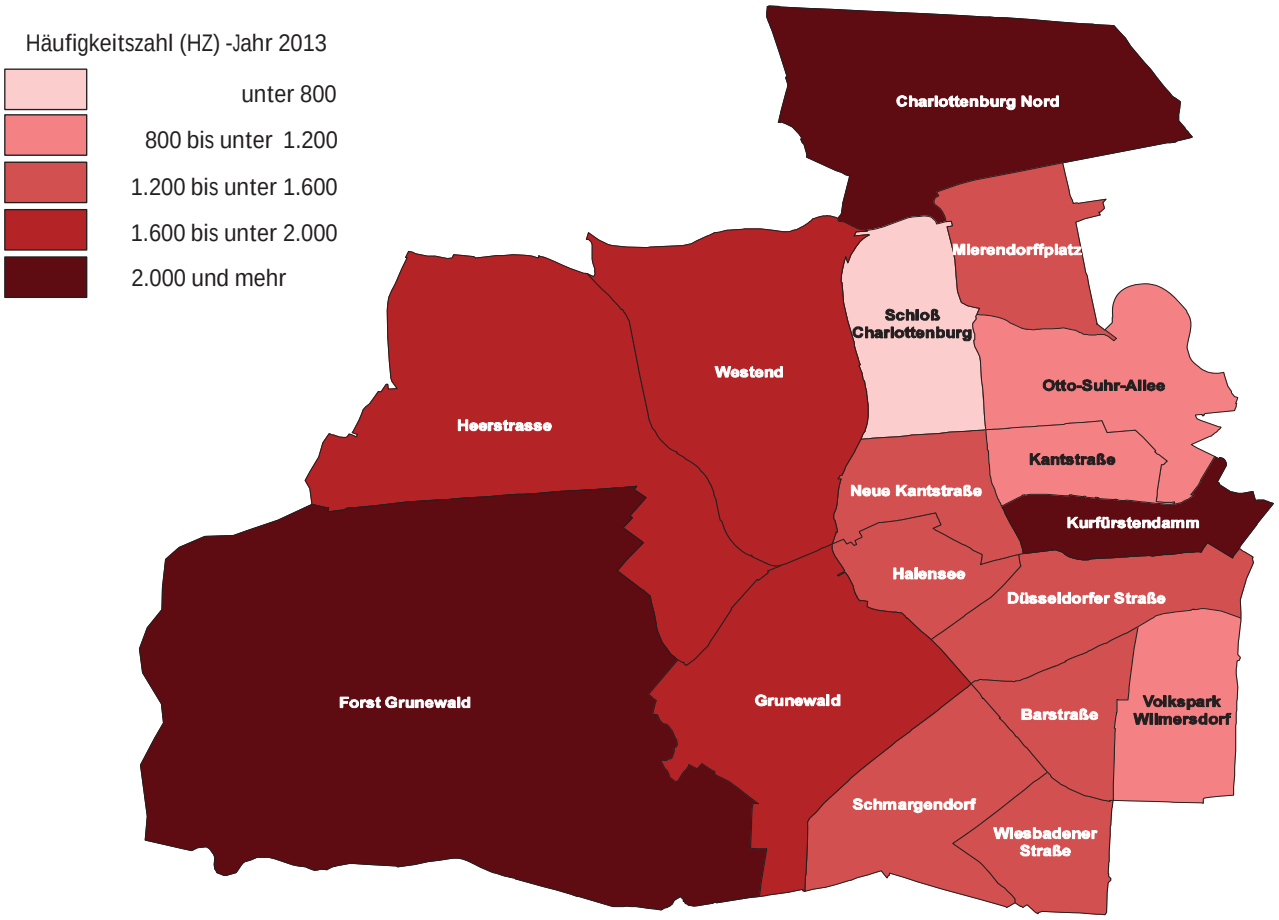

Diebstahl an/aus Kraftfahrzeugen (PKS-Schlüssel 350***, 450***)

Bezirksregion	Jahr 2012		Jahr 2013		Zu-/Abnahme			
	erfasste Fälle	HZ	erfasste Fälle	HZ	Fälle absolut	Fälle in %	HZ absolut	HZ in %
Charlottenburg Nord.....	304	1 681	418	2 264	114	37,5	583	34,7
Heerstraße.....	155	1 240	232	1 839	77	49,7	599	48,3
Westend.....	282	1 077	465	1 745	183	64,9	668	62,0
Schloß Charlottenburg.....	133	575	176	751	43	32,3	176	30,6
Mierendorffplatz.....	211	1 483	201	1 378	- 10	- 4,7	- 105	- 7,1
Otto-Suhr-Allee.....	292	1 146	308	1 195	16	5,5	49	4,3
Neue Kantstraße.....	254	1 108	292	1 260	38	15,0	152	13,7
Kantstraße.....	188	919	198	956	10	5,3	37	4,0
Kurfürstendamm.....	302	2 074	369	2 530	67	22,2	456	22,0
Halensee.....	188	1 324	180	1 248	- 8	- 4,3	- 76	- 5,7
Grunewald.....	268	1 497	330	1 811	62	23,1	314	21,0
Schmargendorf.....	224	1 622	212	1 524	- 12	- 5,4	- 98	- 6,0
Wiesbadener Straße.....	125	693	221	1 223	96	76,8	530	76,5
Düsseldorfer Straße.....	362	1 234	448	1 506	86	23,8	272	22,0
Barstraße.....	160	1 186	199	1 466	39	24,4	280	23,6
Volkspark Wilmersdorf.....	241	745	388	1 183	147	61,0	438	58,8
Forst Grunewald.....	56		33		- 23	x		
nicht zuzuordnen.....	25		16					

Bezirk Berlin Spandau

Diebstahl an/aus Kraftfahrzeugen (Häufigkeitszahl)

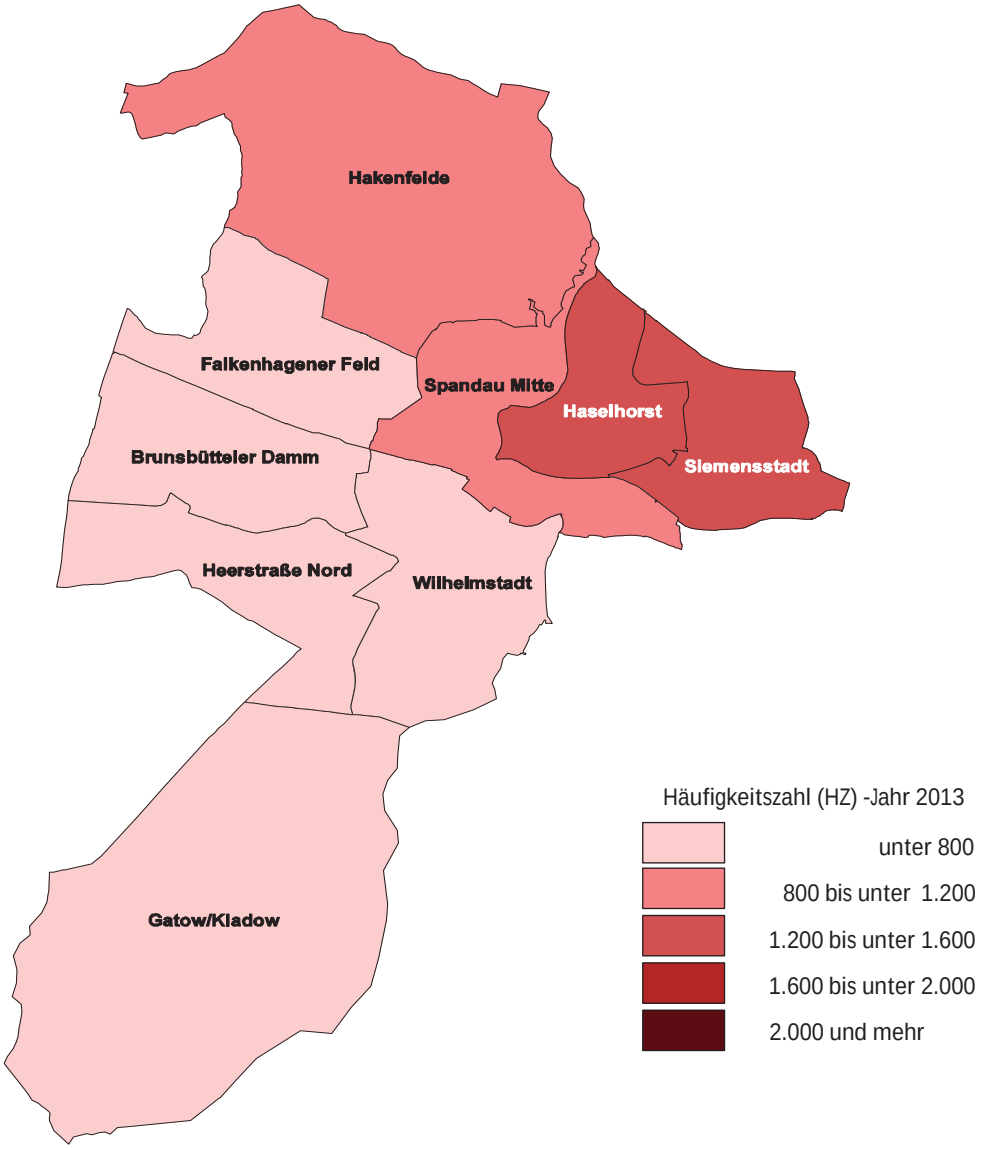

Diebstahl an/aus Kraftfahrzeugen (PKS-Schlüssel 350***, 450***)

Bezirksregion	Jahr 2012		Jahr 2013		Zu-/Abnahme			
	erfasste Fälle	HZ	erfasste Fälle	HZ	Fälle absolut	Fälle in %	HZ absolut	HZ in %
Hakenfelde.....	192	847	187	823	- 5	- 2,6	- 24	- 2,8
Falkenhagener Feld.....	167	428	180	459	13	7,8	31	7,2
Spandau Mitte.....	201	612	291	863	90	44,8	251	41,0
Brunsbütteler Damm.....	109	471	136	588	27	24,8	117	24,8
Heerstraße Nord.....	130	487	167	624	37	28,5	137	28,1
Wilhelmstadt.....	214	631	238	693	24	11,2	62	9,8
Haselhorst.....	208	1 511	180	1 247	- 28	- 13,5	- 264	- 17,5
Siemensstadt.....	111	955	153	1 276	42	37,8	321	33,6
Gatow/Kladow.....	129	726	107	590	- 22	- 17,1	- 136	- 18,7
nicht zuzuordnen.....	9		11					

Bezirk Berlin Steglitz-Zehlendorf

Diebstahl an/aus Kraftfahrzeugen (Häufigkeitszahl)

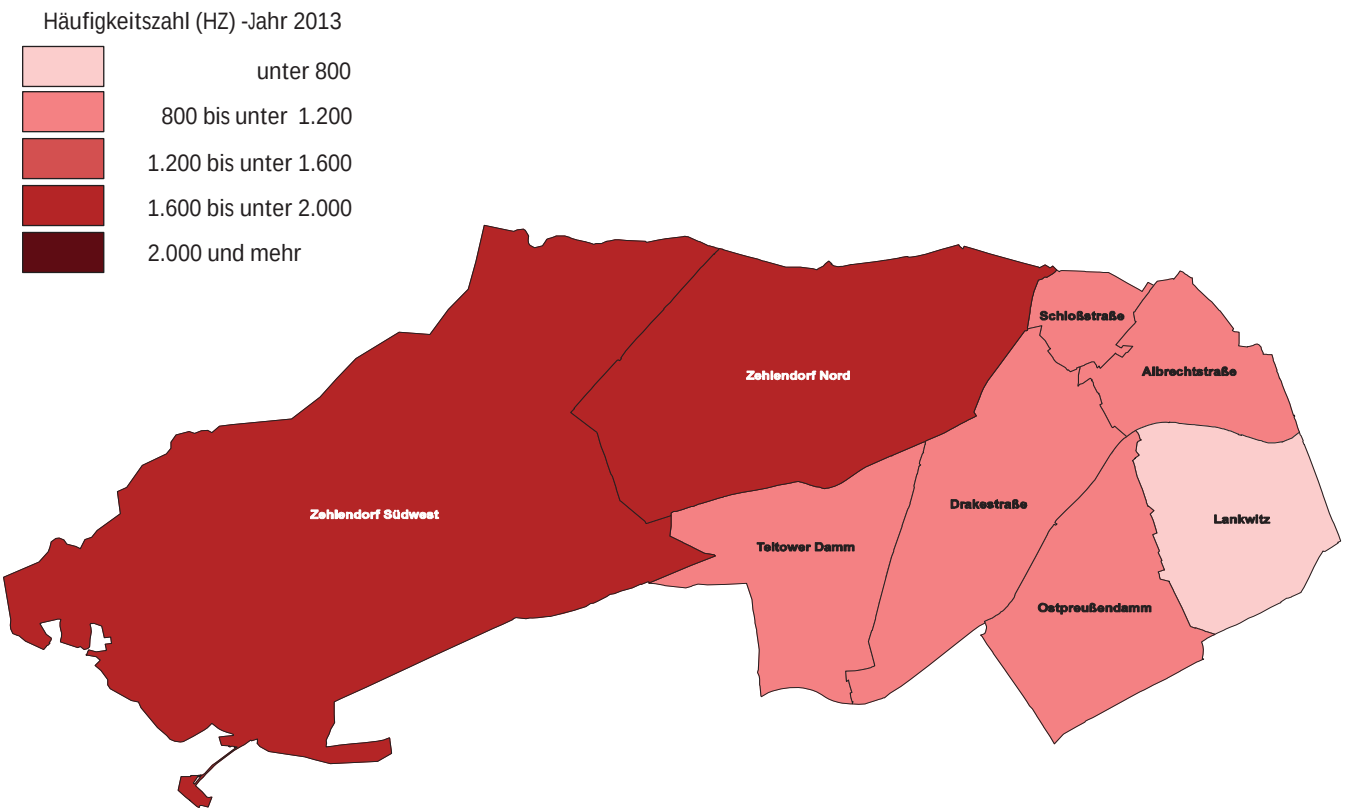

Diebstahl an/aus Kraftfahrzeugen (PKS-Schlüssel 350***, 450***)

Bezirksregion	Jahr 2012		Jahr 2013		Zu-/Abnahme			
	erfasste Fälle	HZ	erfasste Fälle	HZ	Fälle absolut	Fälle in %	HZ absolut	HZ in %
Schloßstraße	227	1 061	193	893	- 34	- 15,0	- 168	- 15,8
Albrechtstraße	347	676	418	807	71	20,5	131	19,4
Lankwitz	200	484	317	759	117	58,5	275	56,8
Ostpreußendamm	244	704	344	984	100	41,0	280	39,8
Teltower Damm	243	743	374	1 141	131	53,9	398	53,6
Drakestraße	312	683	497	1 069	185	59,3	386	56,5
Zehlendorf Südwest	269	1 054	441	1 726	172	63,9	672	63,8
Zehlendorf Nord	519	1 250	684	1 648	165	31,8	398	31,8
nicht zuzuordnen	15		7					

Bezirk Berlin Tempelhof-Schöneberg

Diebstahl an/aus Kraftfahrzeugen (Häufigkeitszahl)

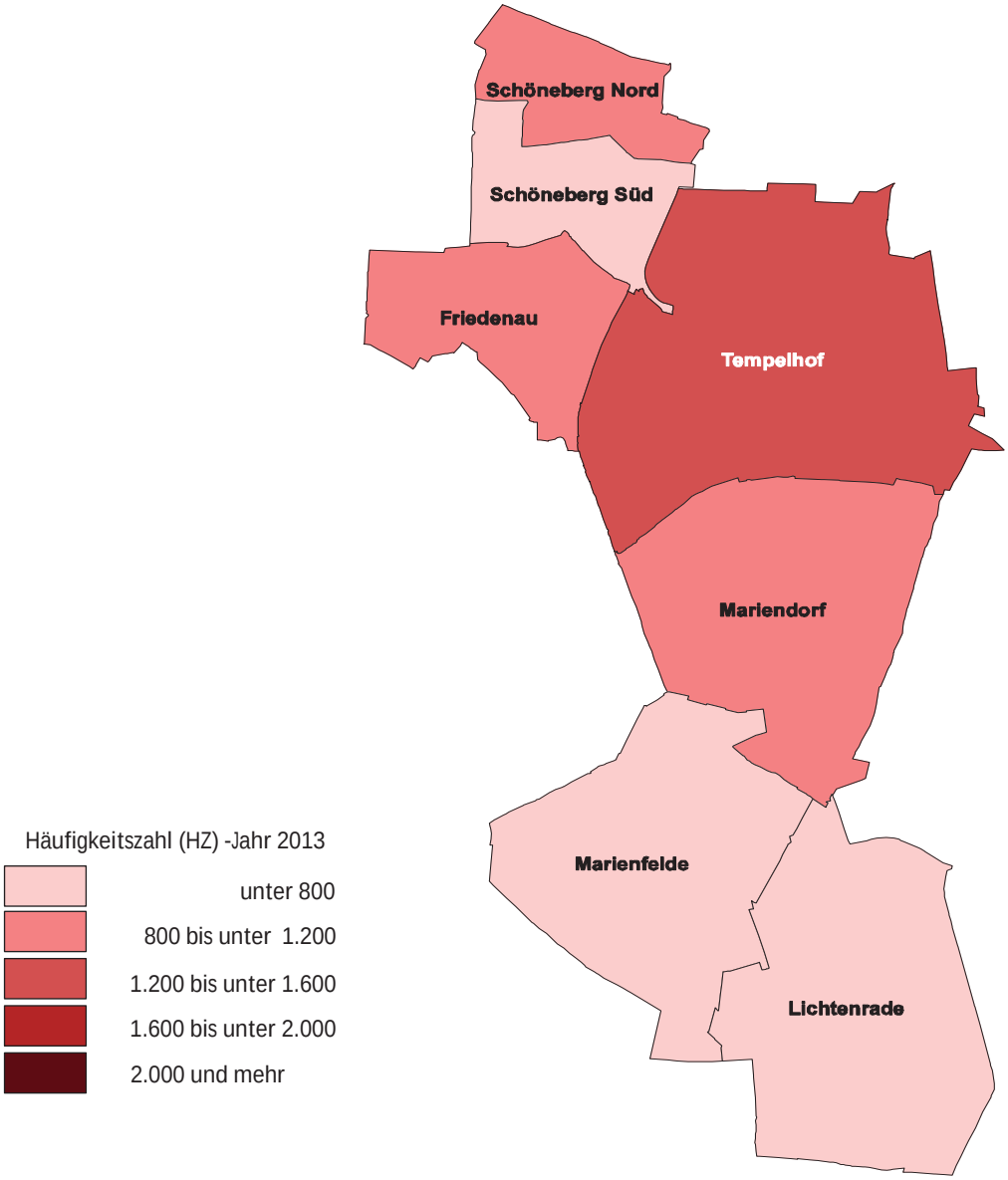

Diebstahl an/aus Kraftfahrzeugen (PKS-Schlüssel 350***, 450***)

Bezirksregion	Jahr 2012		Jahr 2013		Zu-/Abnahme			
	erfasste Fälle	HZ	erfasste Fälle	HZ	Fälle		HZ	
					absolut	in %	absolut	in %
Schöneberg Nord	425	902	508	1 082	83	19,5	180	20,0
Schöneberg Süd	312	656	376	789	64	20,5	133	20,3
Friedenau	329	748	430	969	101	30,7	221	29,5
Tempelhof	753	1 277	791	1 317	38	5,0	40	3,1
Mariendorf	508	1 020	513	1 026	5	1,0	6	0,6
Marienfelde	220	723	238	779	18	8,2	56	7,7
Lichtenrade	421	851	390	785	- 31	- 7,4	- 66	- 7,8
nicht zuzuordnen	5		7					

Bezirk Berlin Neukölln

Diebstahl an/aus Kraftfahrzeugen (Häufigkeitszahl)

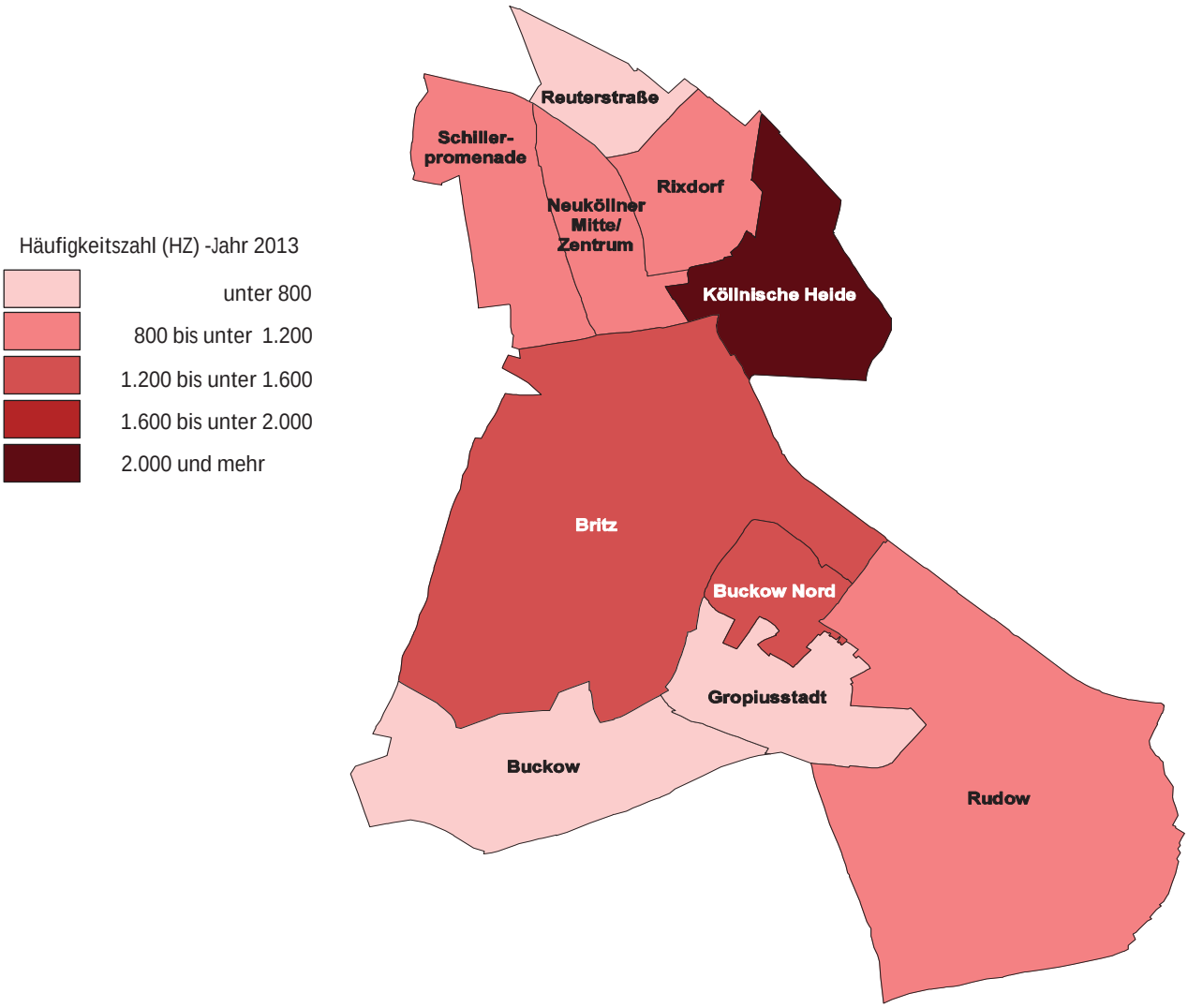

Diebstahl an/aus Kraftfahrzeugen (PKS-Schlüssel 350***, 450***)

Bezirksregion	Jahr 2012		Jahr 2013		Zu-/Abnahme			
	erfasste Fälle	HZ	erfasste Fälle	HZ	Fälle absolut	Fälle in %	HZ absolut	HZ in %
Schillerpromenade	221	715	284	900	63	28,5	185	25,9
Neuköllner Mitte/Zentrum	314	851	437	1 158	123	39,2	307	36,1
Reuterstraße	264	680	244	614	- 20	- 7,6	- 66	- 9,7
Rixdorf	316	813	367	928	51	16,1	115	14,1
Köllnische Heide	303	2 056	349	2 321	46	15,2	265	12,9
Britz	566	1 397	623	1 516	57	10,1	119	8,5
Buckow	225	815	214	768	- 11	- 4,9	- 47	- 5,8
Gropiusstadt	195	541	242	666	47	24,1	125	23,1
Buckow Nord	73	785	115	1 228	42	x	443	(56,4)
Rudow	374	892	441	1 047	67	17,9	155	17,4
nicht zuzuordnen	21		16					

Bezirk Berlin Treptow-Köpenick

Diebstahl an/aus Kraftfahrzeugen (Häufigkeitszahl)

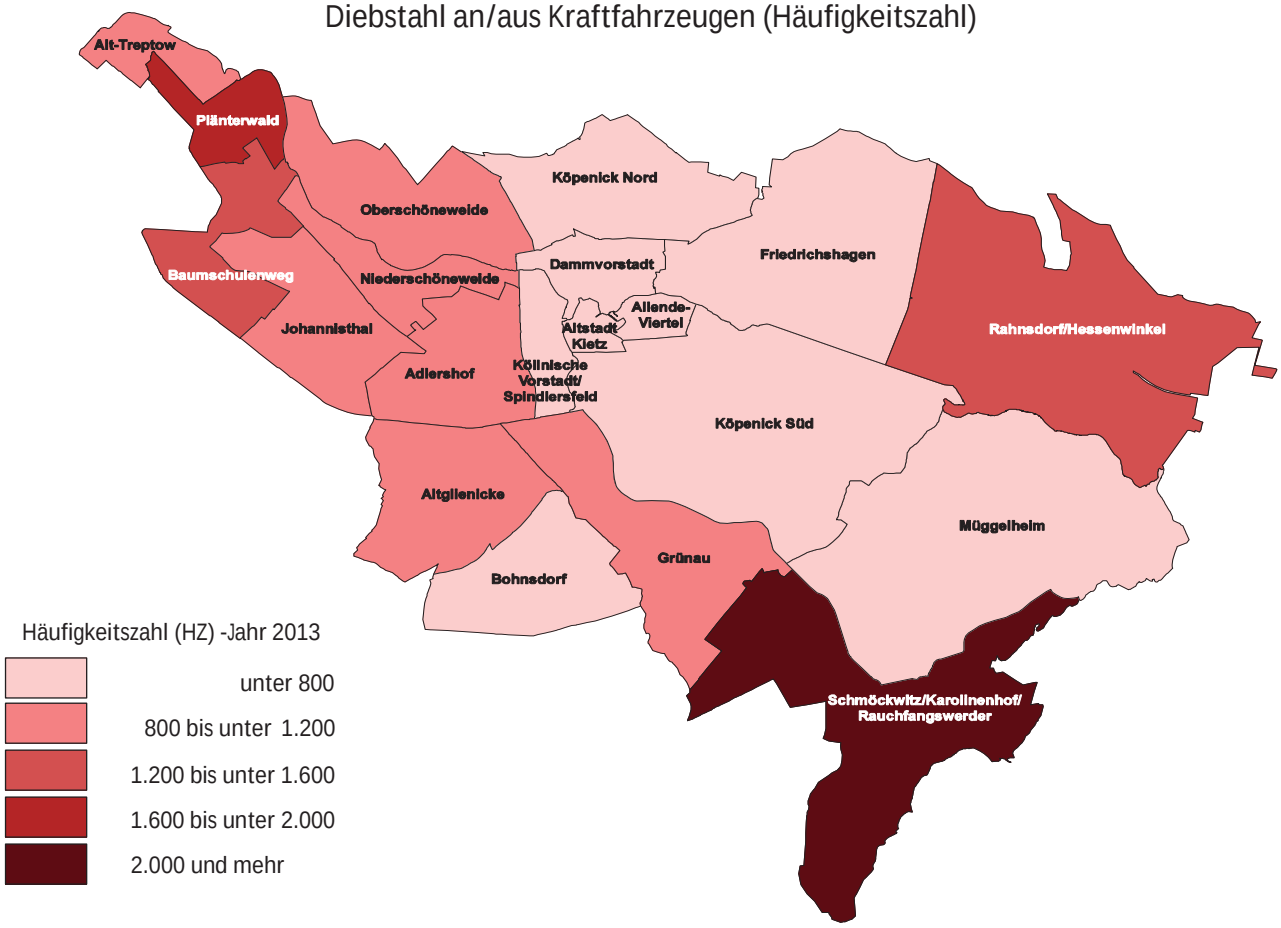

Diebstahl an/aus Kraftfahrzeugen (PKS-Schlüssel 350***, 450***)

Bezirksregion	Jahr 2012		Jahr 2013		Zu-/Abnahme			
	erfasste Fälle	HZ	erfasste Fälle	HZ	Fälle absolut	Fälle in %	HZ absolut	HZ in %
Alt-Treptow	95	869	109	982	14	x	113	(13,0)
Plänterwald	106	983	210	1 938	104	98,1	955	97,2
Baumschulenweg	141	818	211	1 211	70	49,6	393	48,0
Johannisthal	93	508	168	911	75	x	403	(79,3)
Oberschöneweide	147	767	185	938	38	25,9	171	22,3
Niederschöneweide	76	727	93	875	17	x	148	(20,4)
Adlershof	123	799	152	974	29	23,6	175	21,9
Kölln. Vorstadt/Spindlersf.	44	447	54	540	10	x	93	(20,8)
Altglienicke	108	423	228	881	120	111,1	458	108,3
Bohnsdorf	58	487	87	721	29	x	234	(48,0)
Grünau	65	1 204	49	875	- 16	x	- 329	(- 27,3)
Schmöckwitz/Karolinenhof	53	1 305	82	2 035	29	x	730	(55,9)
Köpenick Süd	112	717	123	791	11	9,8	74	10,3
Allende-Viertel	31	508	20	327	- 11	x	- 181	(- 35,6)
Altstadt Kietz	27	393	28	403	1	x	10	(2,5)
Müggelheim	41	630	32	489	- 9	x	- 141	(- 22,4)
Friedrichshagen	89	509	91	521	2	x	12	(2,4)
Rahnsdorf/Hessenwinkel	51	569	141	1 574	90	x	1 005	(176,6)
Dammvorstadt	43	456	66	693	23	x	237	(52,0)
Köpenick Nord	42	342	78	636	36	x	294	(86,0)
nicht zuzuordnen	26		29					

Bezirk Berlin Marzahn-Hellersdorf

Diebstahl an/aus Kraftfahrzeugen (Häufigkeitszahl)

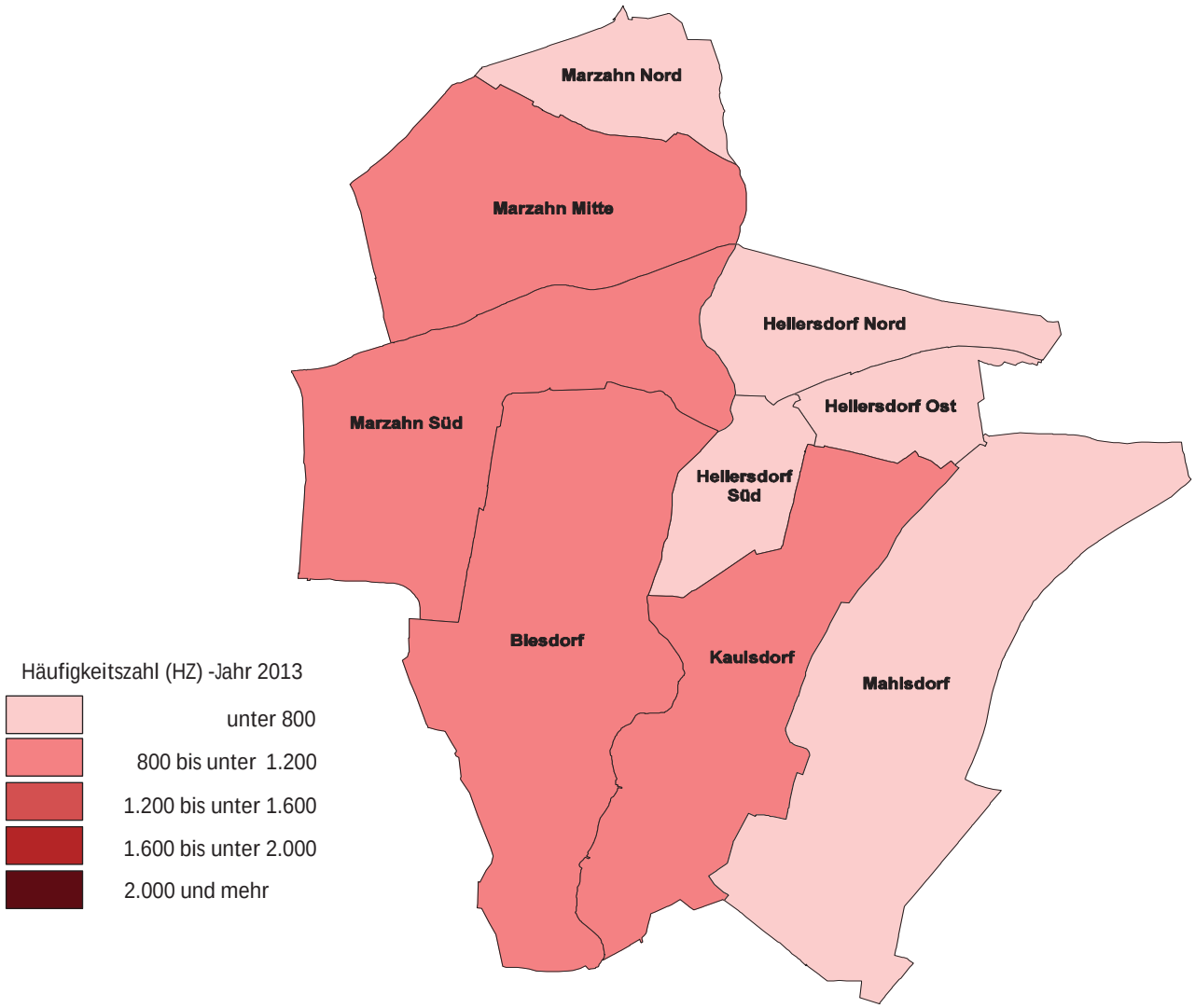

Diebstahl an/aus Kraftfahrzeugen (PKS-Schlüssel 350***, 450***)

Bezirksregion	Jahr 2012		Jahr 2013		Zu-/Abnahme			
	erfasste Fälle	HZ	erfasste Fälle	HZ	Fälle		HZ	
					absolut	in %	absolut	in %
Marzahn Nord	123	543	126	549	3	2,4	6	1,1
Marzahn Mitte	416	920	467	1 024	51	12,3	104	11,3
Marzahn Süd	372	1 030	361	987	- 11	- 3,0	- 43	- 4,2
Hellersdorf Nord	230	701	202	607	- 28	- 12,2	- 94	- 13,4
Hellersdorf Ost	89	482	79	418	- 10	x	- 64	(- 13,3)
Hellersdorf Süd	119	491	121	495	2	1,7	4	0,8
Biesdorf	213	847	290	1 137	77	36,2	290	34,2
Kaulsdorf	89	476	168	901	79	x	425	(89,3)
Mahlsdorf	117	434	215	793	98	83,8	359	82,7
nicht zuzuordnen	10		3					

Bezirk Berlin Lichtenberg

Diebstahl an/aus Kraftfahrzeugen (Häufigkeitszahl)

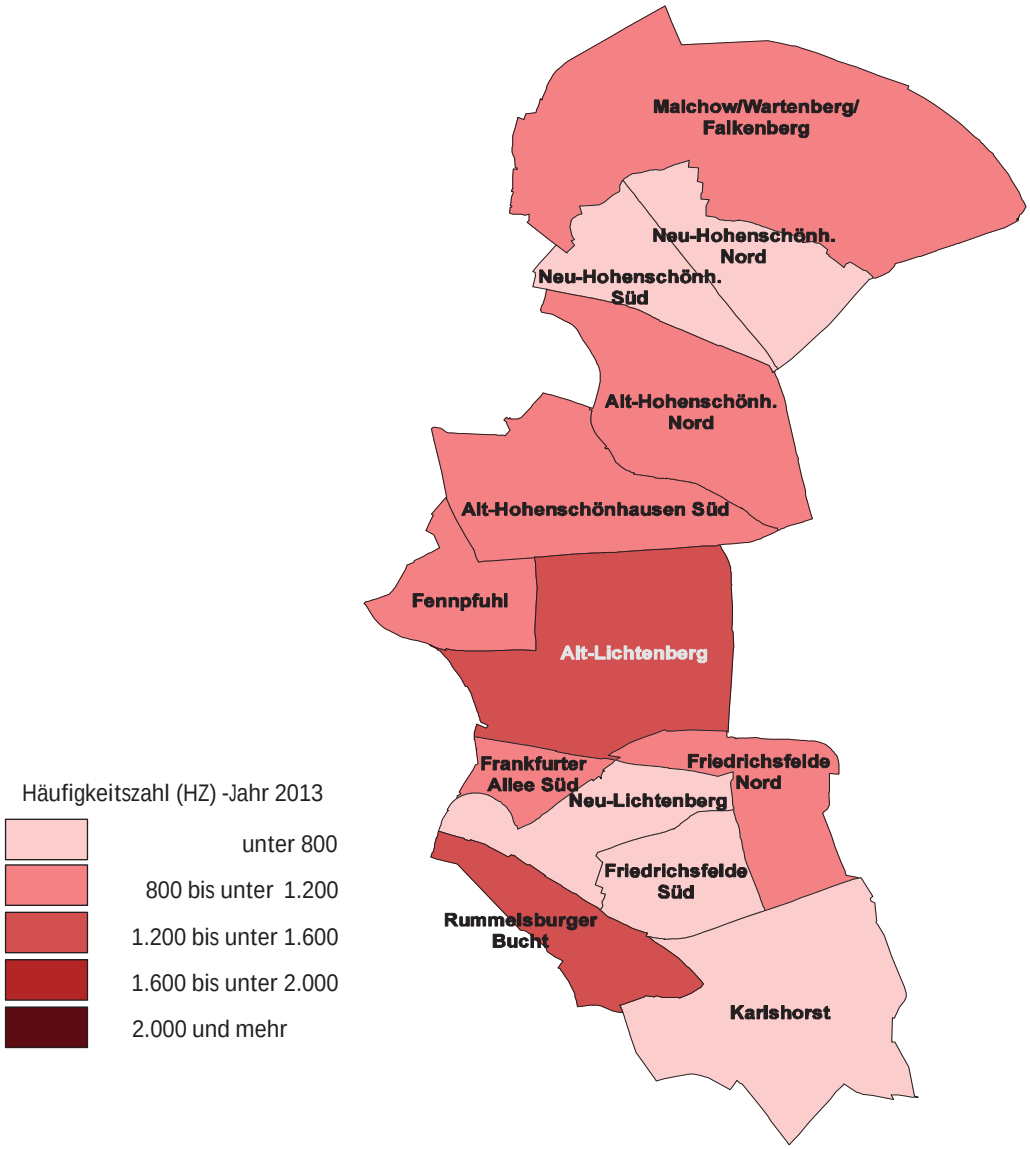

Diebstahl an/aus Kraftfahrzeugen (PKS-Schlüssel 350***, 450***)

Bezirksregion	Jahr 2012		Jahr 2013		Zu-/Abnahme			
	erfasste Fälle	HZ	erfasste Fälle	HZ	Fälle absolut	Fälle in %	HZ absolut	HZ in %
Malchow/Warten-/Falkenberg.....	21	501	41	965	20	x	464	(92,6)
Neu-Hohenschönhausen Nord.....	103	375	125	452	22	21,4	77	20,5
Neu-Hohenschönhausen Süd.....	128	495	130	503	2	1,6	8	1,6
Alt-Hohenschönhausen Nord.....	120	891	145	1 075	25	20,8	184	20,7
Alt-Hohenschönhausen Süd.....	266	905	279	947	13	4,9	42	4,6
Fennpfuhl.....	243	766	262	818	19	7,8	52	6,8
Alt-Lichtenberg.....	328	1 366	327	1 311	- 1	- 0,3	- 55	- 4,0
Frankfurter Allee Süd.....	96	994	106	1 058	10	x	64	(6,4)
Neu-Lichtenberg.....	150	511	208	692	58	38,7	181	35,4
Friedrichsfelde Nord.....	159	1 193	144	1 065	- 15	- 9,4	- 128	- 10,7
Friedrichsfelde Süd.....	142	589	141	574	- 1	- 0,7	- 15	- 2,5
Rummelsburger Bucht.....	69	2 115	45	1 357	- 24	x	- 758	(- 35,8)
Karlshorst.....	137	607	186	798	49	35,8	191	31,5
nicht zuzuordnen.....	17		8					

Bezirk Berlin Reinickendorf

Diebstahl an/aus Kraftfahrzeugen (Häufigkeitszahl)

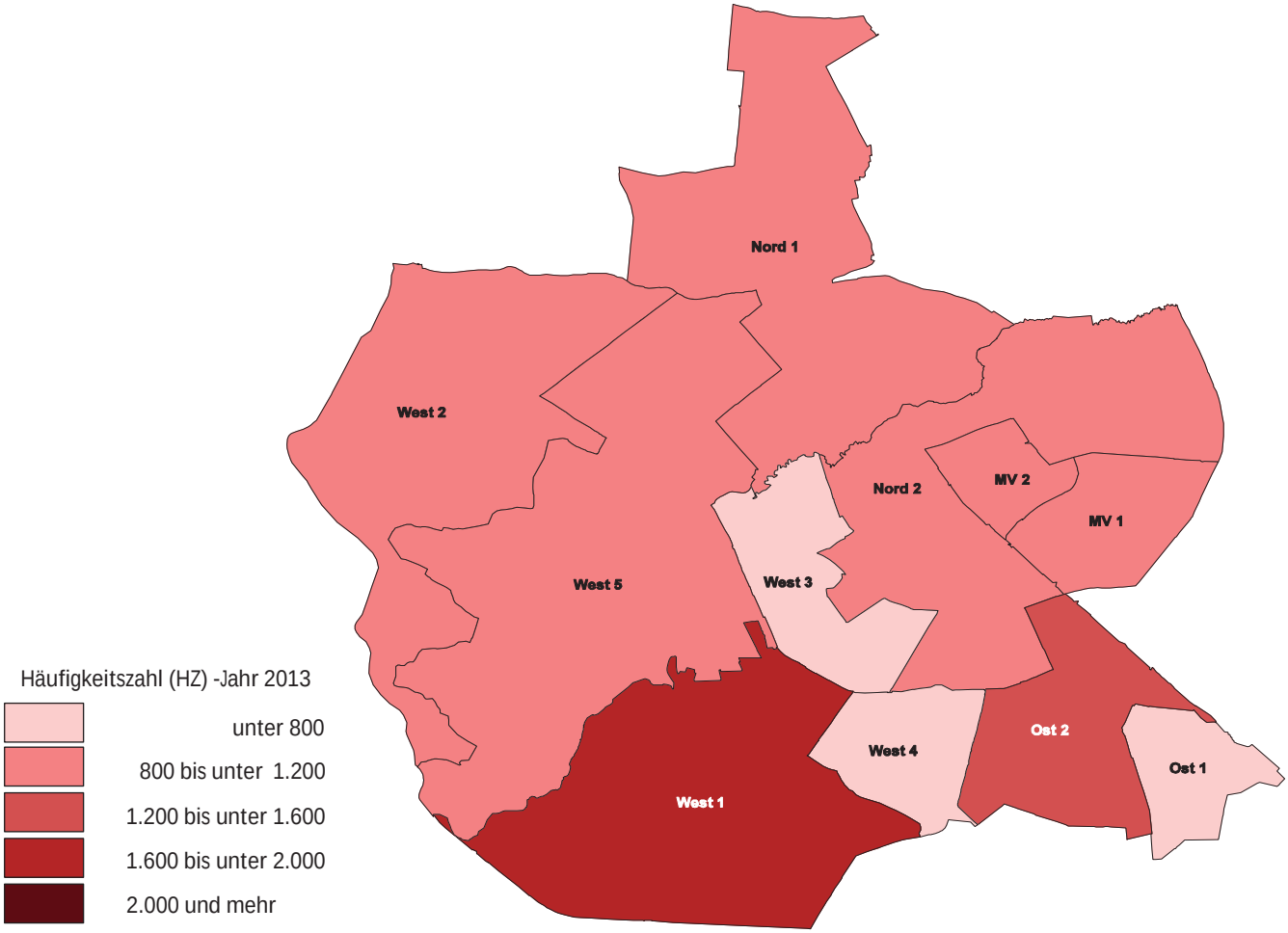

Diebstahl an/aus Kraftfahrzeugen (PKS-Schlüssel 350***, 450***)

Bezirksregion	Jahr 2012		Jahr 2013		Zu-/Abnahme			
	erfasste Fälle	HZ	erfasste Fälle	HZ	Fälle absolut	Fälle in %	HZ absolut	HZ in %
Ost 1	205	799	191	735	- 14	- 6,8	- 64	- 8,0
Ost 2	301	1 180	322	1 245	21	7,0	65	5,5
West 1	406	2 791	254	1 756	- 152	- 37,4	- 1 035	- 37,1
West 4	205	820	187	736	- 18	- 8,8	- 84	- 10,2
West 5	109	1 067	98	952	- 11	- 10,1	- 115	- 10,8
West 2	175	743	261	1 098	86	49,1	355	47,8
Nord 1	293	896	391	1 191	98	33,4	295	32,9
Nord 2	256	877	291	978	35	13,7	101	11,5
MV 1	305	861	328	902	23	7,5	41	4,8
MV 2	75	915	82	964	7	x	49	(5,4)
West 3	123	770	102	638	- 21	- 17,1	- 132	- 17,1
nicht zuzuordnen	11		7					

Berlin - Fahrraddiebstahl (Häufigkeitszahl)

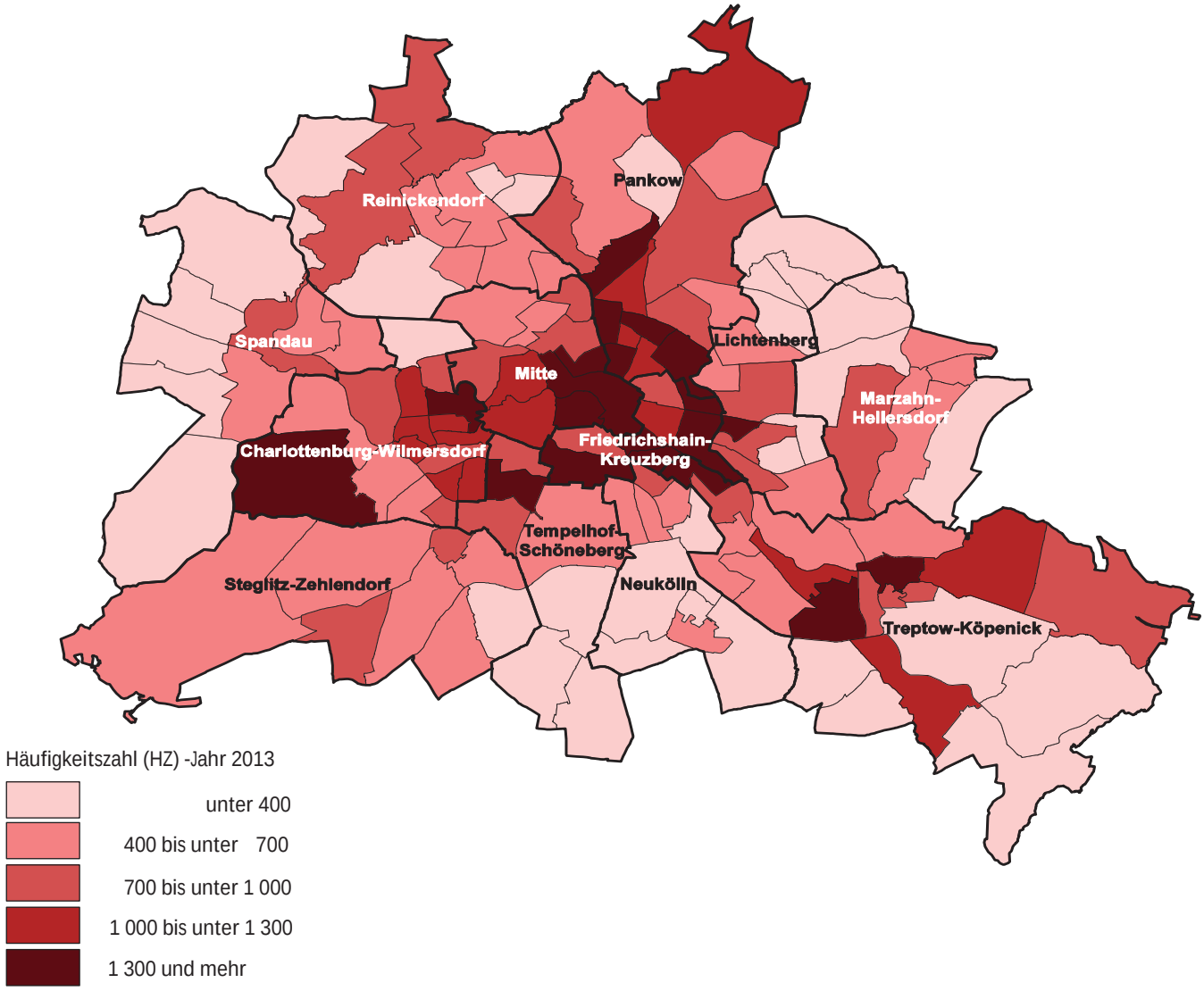

Fahrraddiebstahl (PKS-Schlüssel 3**3**, 4**3**)

Bezirk	Jahr 2012		Jahr 2013		Zu-/Abnahme			
	erfasste Fälle	HZ	erfasste Fälle	HZ	Fälle		HZ	
					absolut	in %	absolut	in %
Mitte	3 358	1 001	3 547	1 032	189	5,6	31	3,1
Friedrichshain-Kreuzberg	3 285	1 231	3 515	1 296	230	7,0	65	5,3
Pankow	4 139	1 127	4 203	1 125	64	1,5	- 2	- 0,2
Charlottenburg-Wilmersdorf	3 173	1 002	2 973	927	- 200	- 6,3	- 75	- 7,5
Spandau	1 058	478	964	429	- 94	- 8,9	- 49	- 10,3
Steglitz-Zehlendorf	1 568	533	1 601	540	33	2,1	7	1,3
Tempelhof-Schöneberg	2 169	663	2 169	659	-	-	- 4	- 0,6
Neukölln	1 453	460	1 558	486	105	7,2	26	5,7
Treptow-Köpenick	1 600	660	1 923	786	323	20,2	126	19,1
Marzahn-Hellersdorf	1 075	429	1 114	440	39	3,6	11	2,6
Lichtenberg	1 418	549	1 474	562	56	3,9	13	2,4
Reinickendorf	1 540	626	1 348	541	- 192	- 12,5	- 85	- 13,6
Berlin, nicht zuzuordnen	193		124					
Berlin -Gesamt-	**26 029**	**772**	**26 513**	**779**	**484**	**1,9**	**7**	**0,9**

Bezirk Berlin Mitte

Fahrraddiebstahl (Häufigkeitszahl)

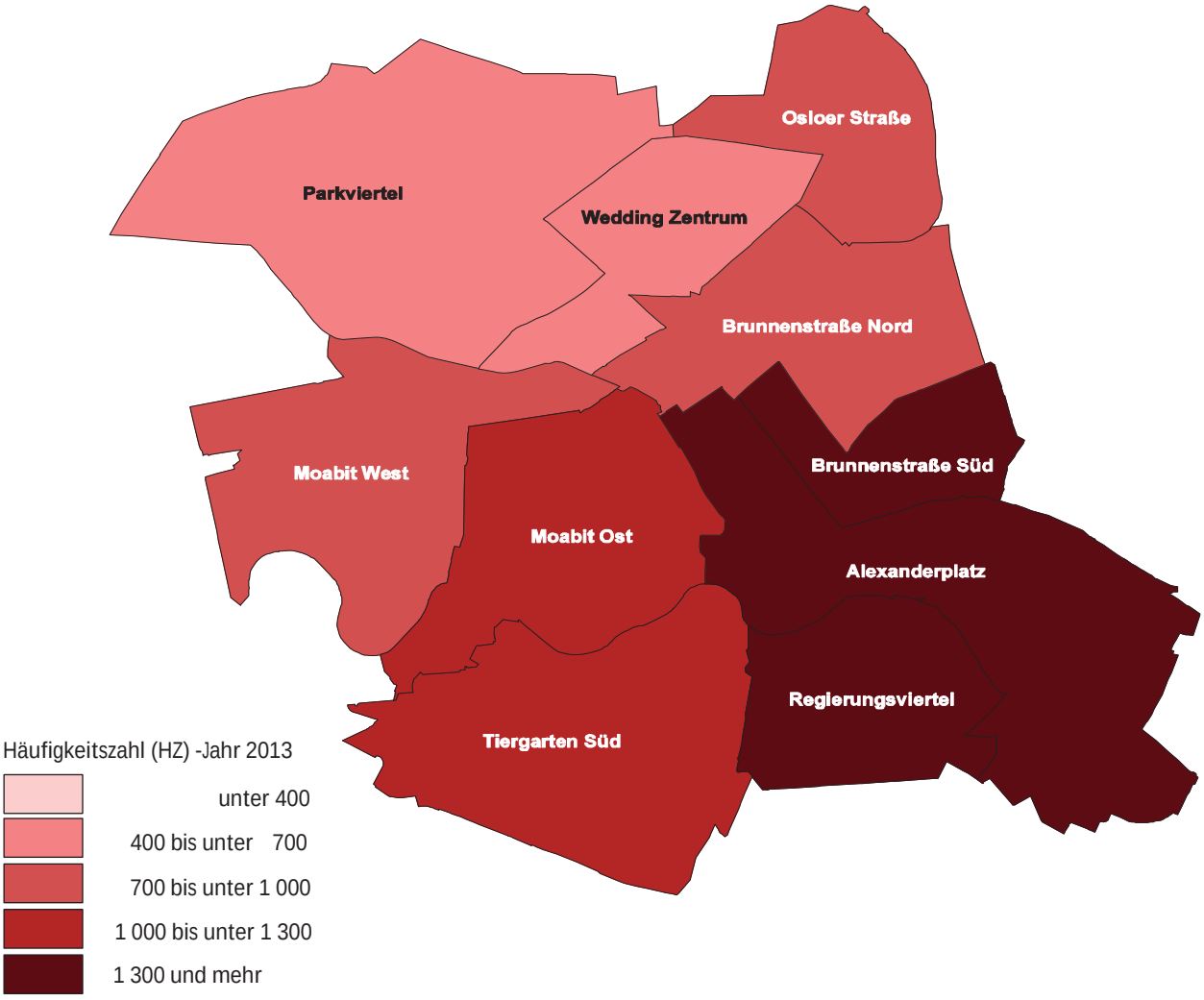

Fahrraddiebstahl (PKS-Schlüssel 3**3**, 4**3**)

Bezirksregion	Jahr 2012		Jahr 2013		Zu-/Abnahme			
	erfasste Fälle	HZ	erfasste Fälle	HZ	Fälle		HZ	
					absolut	in %	absolut	in %
Tiergarten Süd	120	952	149	1 145	29	24,2	193	20,3
Regierungsviertel	170	1 854	254	2 732	84	49,4	878	47,4
Alexanderplatz	822	1 742	926	1 924	104	12,7	182	10,4
Brunnenstraße Süd	396	1 549	358	1 348	- 38	- 9,6	- 201	- 13,0
Moabit West	325	776	336	786	11	3,4	10	1,3
Moabit Ost	337	968	353	1 000	16	4,7	32	3,3
Osloer Straße	280	799	279	771	- 1	- 0,4	- 28	- 3,5
Brunnenstraße Nord	218	618	269	751	51	23,4	133	21,5
Parkviertel	365	881	290	685	- 75	- 20,5	- 196	- 22,2
Wedding Zentrum	294	560	319	590	25	8,5	30	5,4
nicht zuzuordnen	31	-	14	-				

Bezirk Berlin Friedrichshain-Kreuzberg

Fahrraddiebstahl (Häufigkeitszahl)

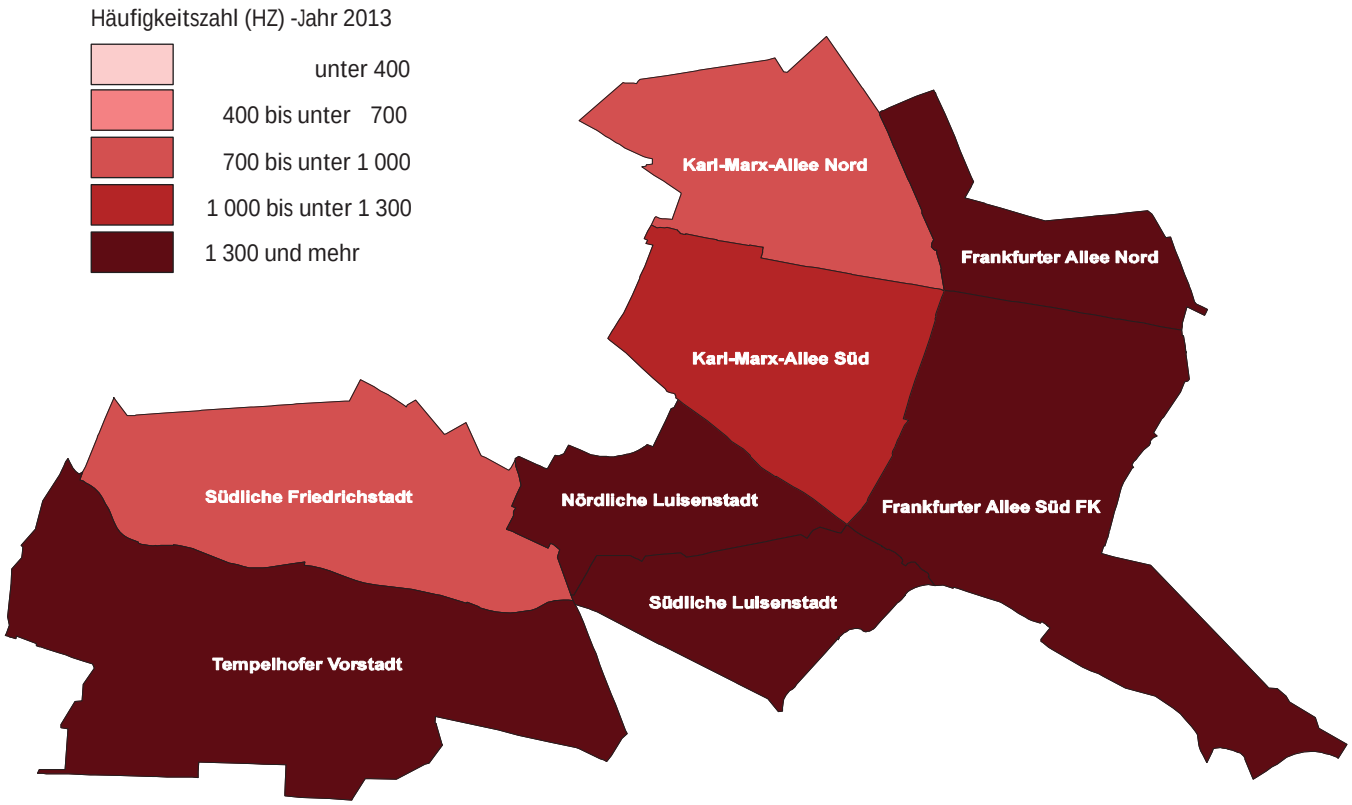

Fahrraddiebstahl (PKS-Schlüssel 3**3**, 4**3**)

Bezirksregion	Jahr 2012		Jahr 2013		Zu-/Abnahme			
	erfasste Fälle	HZ	erfasste Fälle	HZ	Fälle		HZ	
					absolut	in %	absolut	in %
Südliche Friedrichstadt.....	321	824	345	873	24	7,5	49	5,9
Tempelhofer Vorstadt.....	913	1 499	935	1 509	22	2,4	10	0,7
Nördliche Luisenstadt.....	311	1 392	351	1 557	40	12,9	165	11,9
Südliche Luisenstadt.....	347	1 330	371	1 403	24	6,9	73	5,5
Karl-Marx-Allee Nord.....	185	831	184	819	- 1	- 0,5	- 12	- 1,4
Karl-Marx-Allee Süd.....	299	1 303	267	1 140	- 32	- 10,7	- 163	- 12,5
Frankfurter Allee Nord.....	286	1 053	395	1 431	109	38,1	378	35,9
Frankfurter Allee Süd FK.....	616	1 333	660	1 397	44	7,1	64	4,8
nicht zuzuordnen.....	7		7					

Bezirk Berlin Pankow

Fahrraddiebstahl (Häufigkeitszahl)

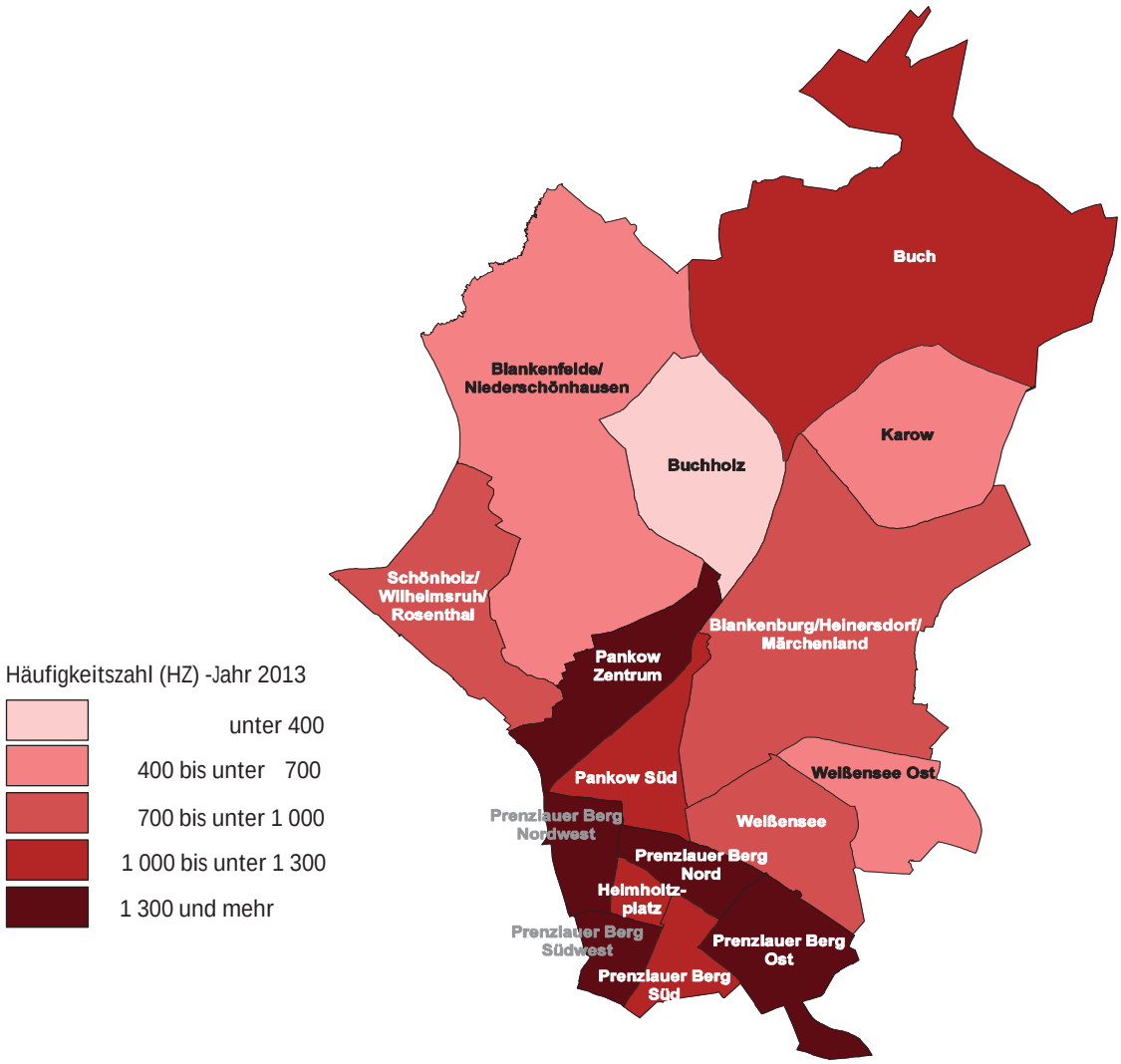

Fahrraddiebstahl (PKS-Schlüssel 3**3**, 4**3**)

Bezirksregion	Jahr 2012		Jahr 2013		Zu-/Abnahme			
	erfasste Fälle	HZ	erfasste Fälle	HZ	Fälle absolut	Fälle in %	HZ absolut	HZ in %
Buch	199	1 526	143	1 056	- 56	- 28,1	- 470	- 30,8
Blankenfelde/Niederschönhausen	148	585	168	646	20	13,5	61	10,4
Buchholz	56	334	45	265	- 11	x	- 69	(- 20,7)
Karow	183	979	101	542	- 82	- 44,8	- 437	- 44,6
Blankenburg/Heinersdorf	149	1 055	121	856	- 28	- 18,8	- 199	- 18,9
Pankow Süd	388	1 219	392	1 207	4	1,0	- 12	- 1,0
Schönholz/Wilhelmsruh/Rosenthal	111	648	126	734	15	13,5	86	13,3
Pankow Zentrum	511	1 575	570	1 710	59	11,5	135	8,6
Weißensee	219	665	251	747	32	14,6	82	12,3
Weißensee Ost	74	493	61	403	- 13	x	- 90	(- 18,3)
Prenzlauer Berg Nordwest	406	1 719	407	1 678	1	0,2	- 41	- 2,4
Prenzlauer Berg Nord	407	1 577	452	1 733	45	11,1	156	9,9
Helmholtzplatz	283	1 335	279	1 288	- 4	- 1,4	- 47	- 3,5
Prenzlauer Berg Ost	289	1 190	337	1 358	48	16,6	168	14,1
Prenzlauer Berg Südwest	381	1 572	349	1 407	- 32	- 8,4	- 165	- 10,5
Prenzlauer Berg Süd	326	1 058	394	1 265	68	20,9	207	19,6
nicht zuzuordnen	9		7					

Bezirk Berlin Charlottenburg-Wilmersdorf

Fahrraddiebstahl (Häufigkeitszahl)

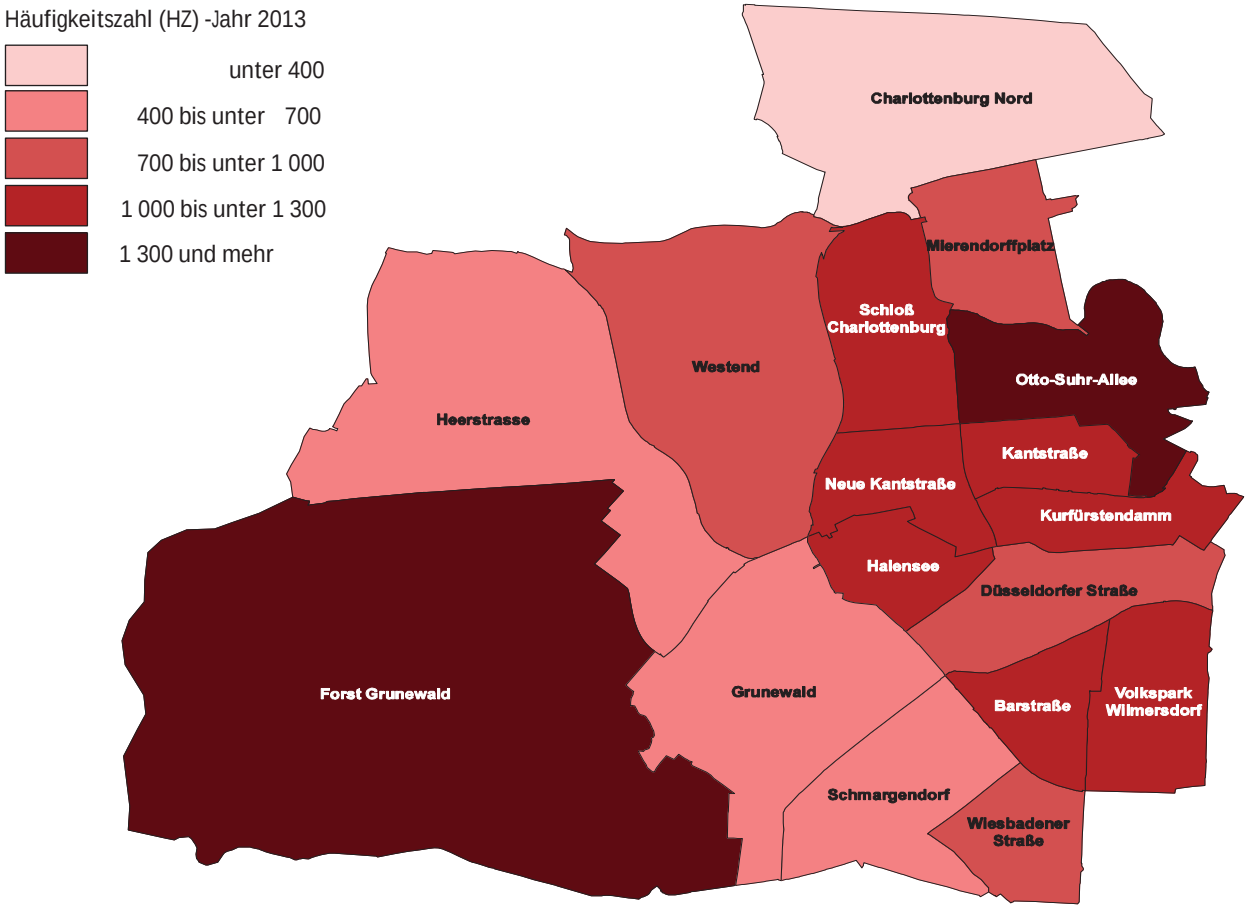

Fahrraddiebstahl (PKS-Schlüssel 3**3**, 4**3**)

Bezirksregion	Jahr 2012		Jahr 2013		Zu-/Abnahme			
	erfasste Fälle	HZ	erfasste Fälle	HZ	Fälle absolut	Fälle in %	HZ absolut	HZ in %
Charlottenburg Nord.....	60	332	65	352	5	x	20	(6,0)
Heerstraße.....	58	464	56	444	- 2	x	- 20	(- 4,3)
Westend.....	170	649	193	724	23	13,5	75	11,6
Schloß Charlottenburg.....	288	1 244	256	1 093	- 32	- 11,1	- 151	- 12,1
Mierendorffplatz.....	148	1 040	103	706	- 45	- 30,4	- 334	- 32,1
Otto-Suhr-Allee.....	429	1 684	355	1 377	- 74	- 17,2	- 307	- 18,2
Neue Kantstraße.....	298	1 300	278	1 199	- 20	- 6,7	- 101	- 7,8
Kantstraße.....	248	1 212	268	1 293	20	8,1	81	6,7
Kurfürstendamm.....	197	1 353	172	1 179	- 25	- 12,7	- 174	- 12,9
Halensee.....	156	1 099	172	1 192	16	10,3	93	8,5
Grunewald.....	84	469	82	450	- 2	x	- 19	(- 4,1)
Schmargendorf.....	77	557	69	496	- 8	x	- 61	(- 11,0)
Wiesbadener Straße.....	129	716	127	703	- 2	- 1,6	- 13	- 1,8
Düsseldorfer Straße.....	301	1 026	263	884	- 38	- 12,6	- 142	- 13,8
Barstraße.....	142	1 053	154	1 135	12	8,5	82	7,8
Volkspark Wilmersdorf.....	378	1 168	356	1 085	- 22	- 5,8	- 83	- 7,1
Forst Grunewald.....	5		4		- 1	x		
nicht zuzuordnen.....	5							

Bezirk Berlin Spandau

Fahrraddiebstahl (Häufigkeitszahl)

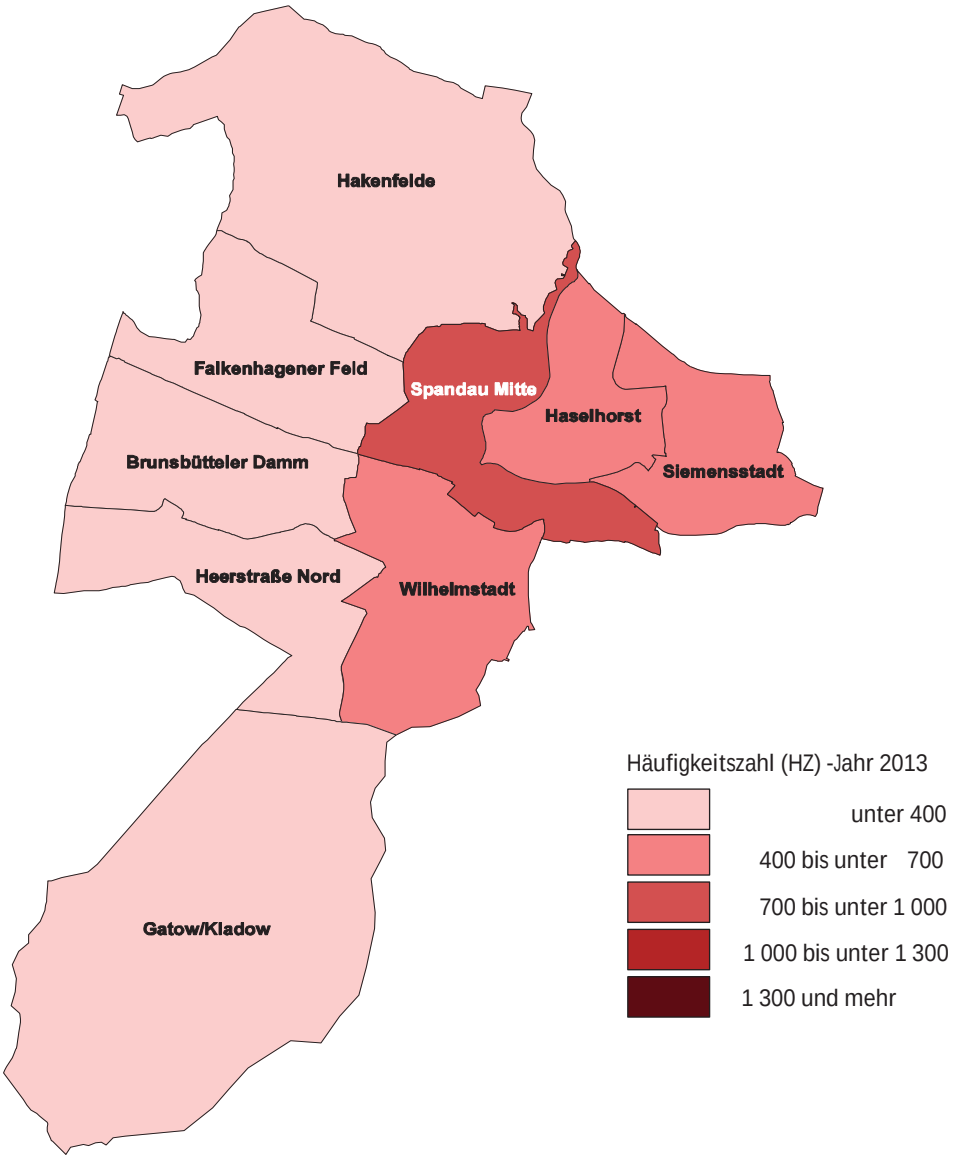

Fahrraddiebstahl (PKS-Schlüssel 3**3**, 4**3**)

Bezirksregion	Jahr 2012		Jahr 2013		Zu-/Abnahme			
	erfasste Fälle	HZ	erfasste Fälle	HZ	Fälle absolut	Fälle in %	HZ absolut	HZ in %
Hakenfelde.....	80	353	56	247	- 24	x	- 106	(- 30,0)
Falkenhagener Feld.....	115	295	146	372	31	27,0	77	26,1
Spandau Mitte.....	279	849	267	792	- 12	- 4,3	- 57	- 6,7
Brunsbütteler Damm.....	64	276	62	268	- 2	x	- 8	(- 2,9)
Heerstraße Nord.....	67	251	71	265	4	x	14	(5,6)
Wilhelmstadt.....	235	693	188	547	- 47	- 20,0	- 146	- 21,1
Haselhorst.....	90	654	59	409	- 31	x	- 245	(- 37,5)
Siemensstadt.....	84	723	83	692	- 1	x	- 31	(- 4,3)
Gatow/Kladow.....	34	191	25	138	- 9	x	- 53	(- 27,7)
nicht zuzuordnen.....	10		7					

Bezirk Berlin Steglitz-Zehlendorf

Fahrraddiebstahl (Häufigkeitszahl)

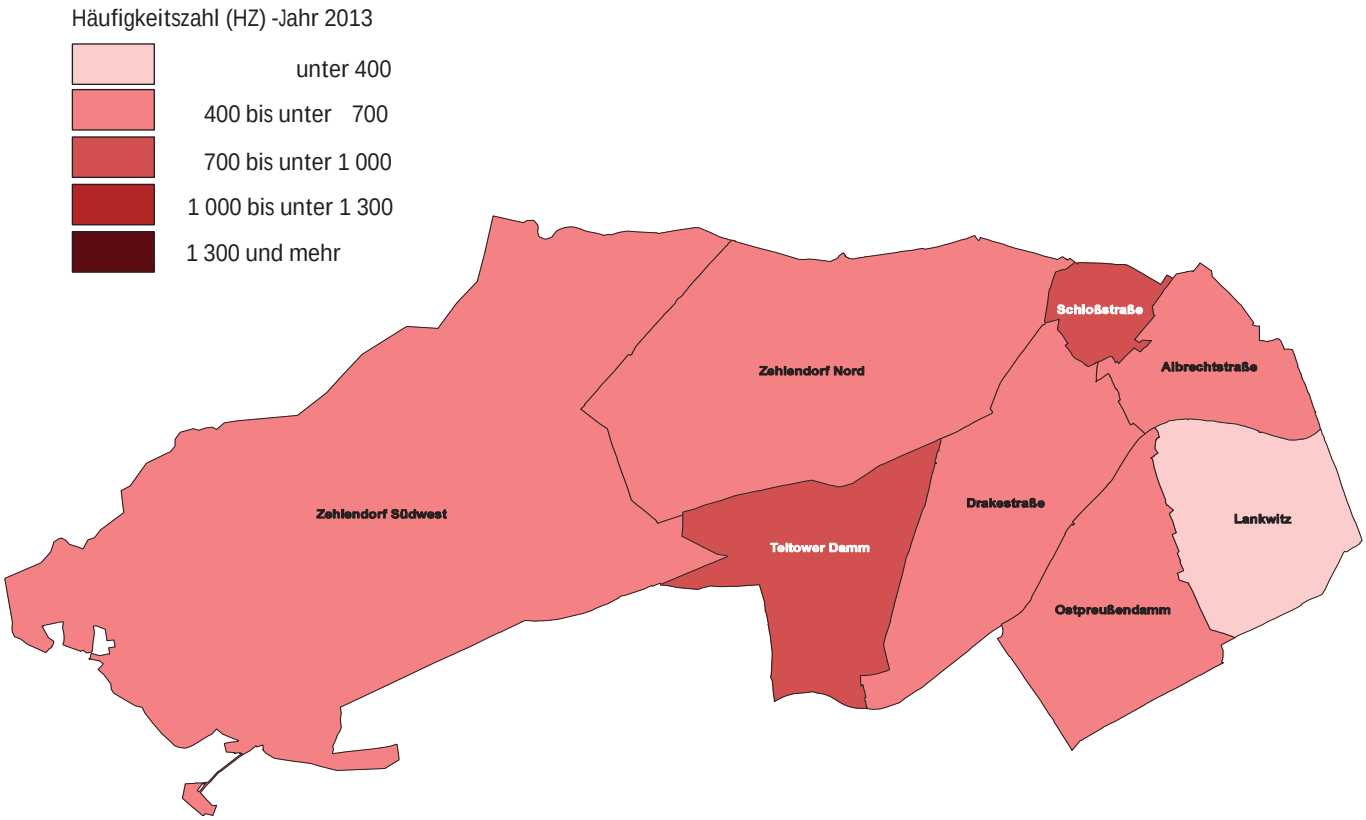

Fahrraddiebstahl (PKS-Schlüssel 3**3**, 4**3**)

Bezirksregion	Jahr 2012		Jahr 2013		Zu-/Abnahme			
	erfasste Fälle	HZ	erfasste Fälle	HZ	Fälle absolut	Fälle in %	HZ absolut	HZ in %
Schloßstraße	184	860	176	814	- 8	- 4,3	- 46	- 5,3
Albrechtstraße	202	393	232	448	30	14,9	55	14,0
Lankwitz	104	252	122	292	18	17,3	40	15,9
Ostpreußendamm	194	560	188	538	- 6	- 3,1	- 22	- 3,9
Teltower Damm	301	921	284	866	- 17	- 5,6	- 55	- 6,0
Drakestraße	220	481	222	477	2	0,9	- 4	- 0,8
Zehlendorf Südwest	95	372	149	583	54	x	211	(56,7)
Zehlendorf Nord	250	602	226	544	- 24	- 9,6	- 58	- 9,6
nicht zuzuordnen	18		2					

Bezirk Berlin Tempelhof-Schöneberg

Fahrraddiebstahl (Häufigkeitszahl)

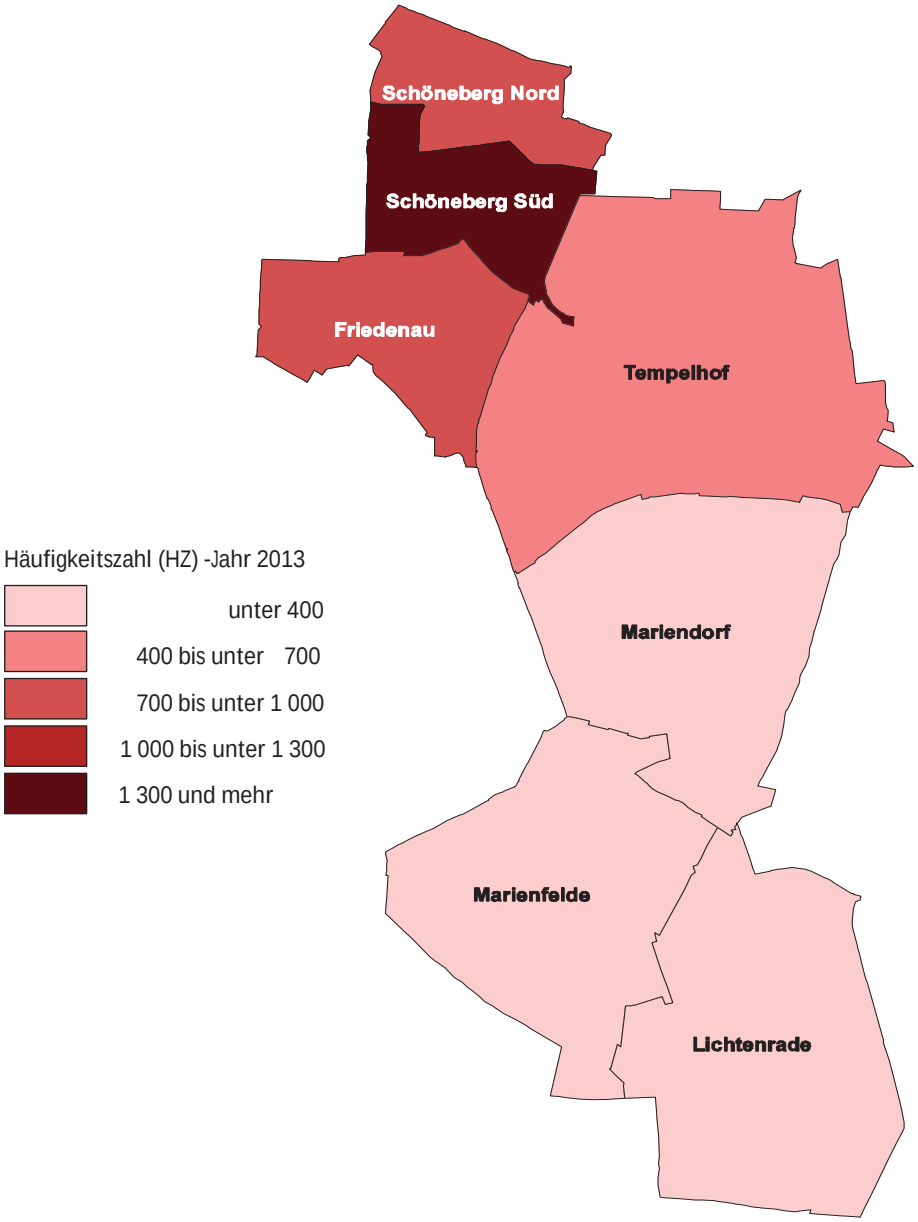

Fahrraddiebstahl (PKS-Schlüssel 3**3**, 4**3**)

Bezirksregion	Jahr 2012		Jahr 2013		Zu-/Abnahme			
	erfasste Fälle	HZ	erfasste Fälle	HZ	Fälle		HZ	
					absolut	in %	absolut	in %
Schöneberg Nord	481	1 021	447	952	- 34	- 7,1	- 69	- 6,8
Schöneberg Süd	557	1 172	627	1 315	70	12,6	143	12,2
Friedenau	397	902	424	955	27	6,8	53	5,9
Tempelhof	352	597	348	580	- 4	- 1,1	- 17	- 2,8
Mariendorf	127	255	140	280	13	10,2	25	9,8
Marienfelde	129	424	78	255	- 51	- 39,5	- 169	- 39,9
Lichtenrade	118	239	98	197	- 20	- 16,9	- 42	- 17,6
nicht zuzuordnen	8		7					

Bezirk Berlin Neukölln

Fahrraddiebstahl (Häufigkeitszahl)

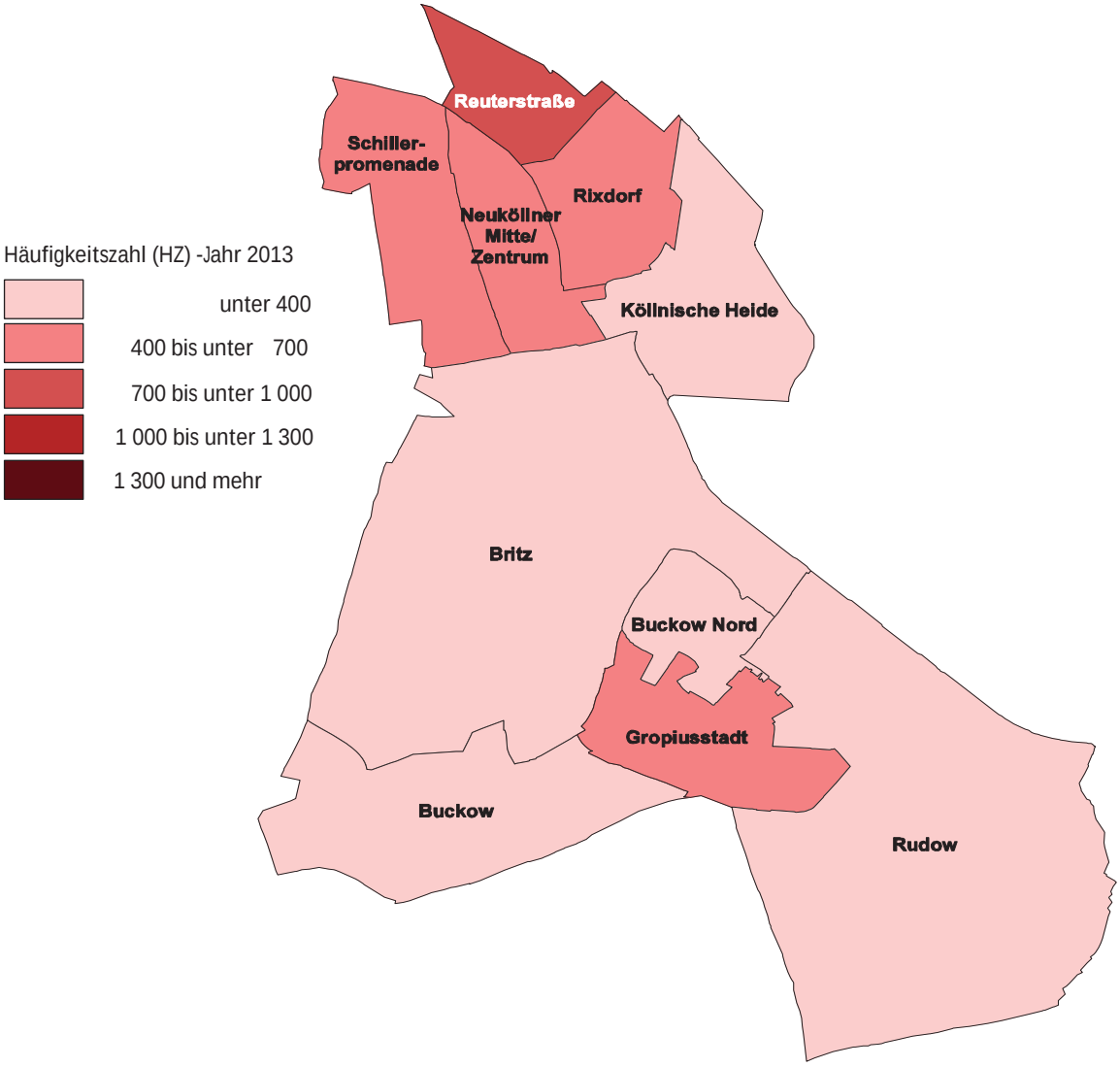

Fahrraddiebstahl (PKS-Schlüssel 3**3**, 4**3**)

Bezirksregion	Jahr 2012		Jahr 2013		Zu-/Abnahme			
	erfasste Fälle	HZ	erfasste Fälle	HZ	Fälle absolut	Fälle in %	HZ absolut	HZ in %
Schillerpromenade	177	572	201	637	24	13,6	65	11,4
Neuköllner Mitte/Zentrum	175	474	226	599	51	29,1	125	26,4
Reuterstraße	310	798	300	755	- 10	- 3,2	- 43	- 5,4
Rixdorf	261	671	269	681	8	3,1	10	1,5
Köllnische Heide	44	299	34	226	- 10	x	- 73	(- 24,4)
Britz	169	417	156	380	- 13	- 7,7	- 37	- 8,9
Buckow	45	163	39	140	- 6	x	- 23	(- 14,1)
Gropiusstadt	140	388	164	451	24	17,1	63	16,2
Buckow Nord	12	129	25	267	13	x	138	(107,0)
Rudow	117	279	144	342	27	23,1	63	22,6
nicht zuzuordnen	3							

Bezirk Berlin Treptow-Köpenick

Fahrraddiebstahl (Häufigkeitszahl)

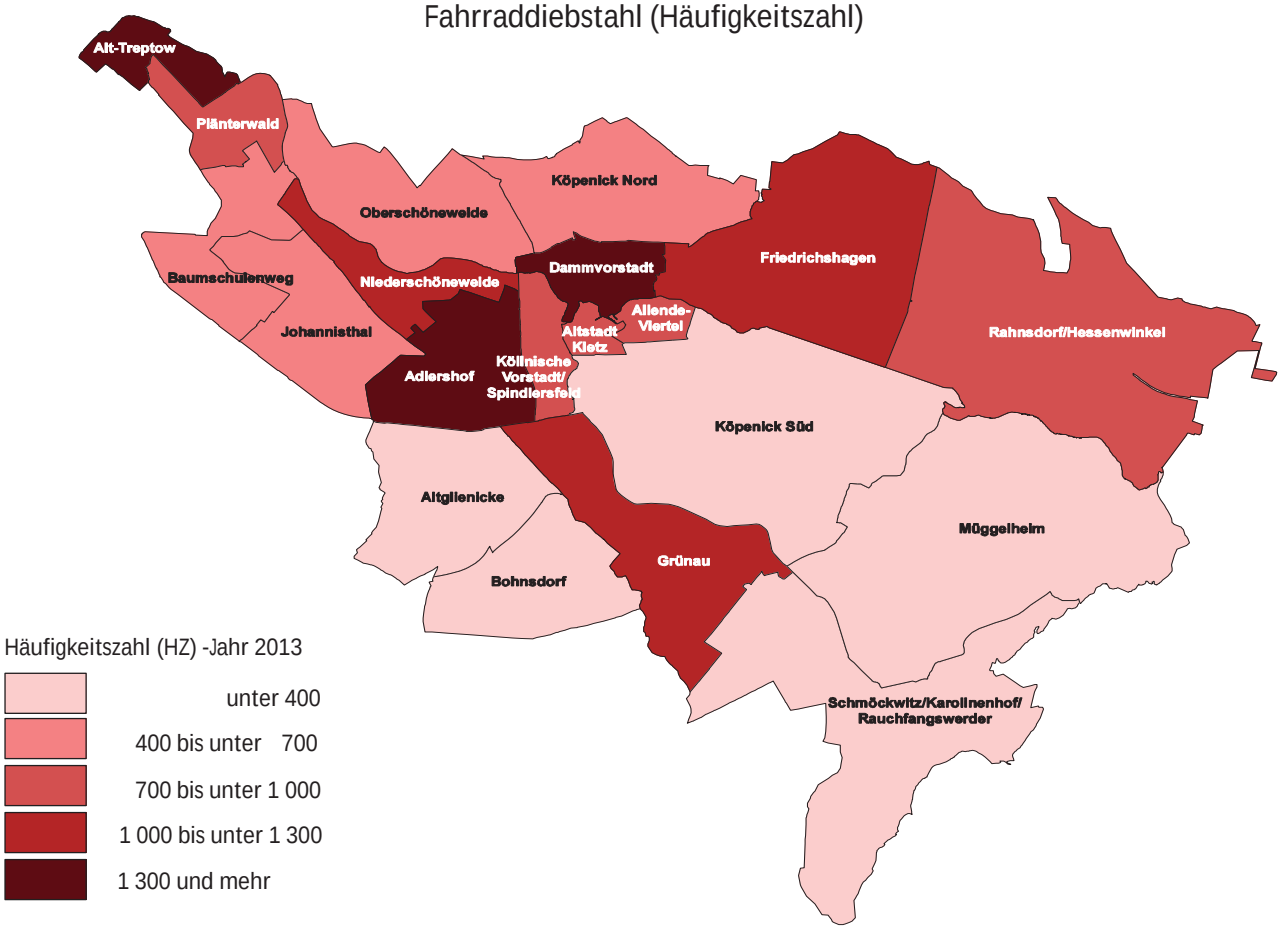

Fahrraddiebstahl (PKS-Schlüssel 3**3**, 4**3**)

Bezirksregion	Jahr 2012		Jahr 2013		Zu-/Abnahme			
	erfasste Fälle	HZ	erfasste Fälle	HZ	Fälle absolut	Fälle in %	HZ absolut	HZ in %
Alt-Treptow	198	1 812	228	2 055	30	15,2	243	13,4
Plänterwald	66	612	77	711	11	x	99	(16,2)
Baumschulenweg	81	470	100	574	19	x	104	(22,1)
Johannisthal	42	229	75	407	33	x	178	(77,7)
Oberschöneweide	69	360	119	604	50	x	244	(67,8)
Niederschöneweide	100	957	133	1 251	33	33,0	294	30,7
Adlershof	164	1 066	204	1 307	40	24,4	241	22,6
Kölln. Vorstadt/Spindlersf.	74	752	75	749	1	x	- 3	(- 0,4)
Altglienicke	93	364	97	375	4	x	11	(3,0)
Bohnsdorf	37	311	43	356	6	x	45	(14,5)
Grünau	63	1 167	72	1 285	9	x	118	(10,1)
Schmöckwitz/Karolinenhof	4	98	3	74	- 1	x	- 24	x
Köpenick Süd	68	435	61	392	- 7	x	- 43	(- 9,9)
Allende-Viertel	36	590	51	833	15	x	243	(41,2)
Altstadt Kietz	57	830	61	879	4	x	49	(5,9)
Müggelheim	21	323	7	107	- 14	x	- 216	(- 66,9)
Friedrichshagen	172	984	221	1 265	49	28,5	281	28,6
Rahnsdorf/Hessenwinkel	105	1 171	69	770	- 36	- 34,3	- 401	- 34,2
Dammvorstadt	93	987	163	1 712	70	x	725	(73,5)
Köpenick Nord	43	350	59	481	16	x	131	(37,4)
nicht zuzuordnen	14		5					

Bezirk Berlin Marzahn-Hellersdorf

Fahrraddiebstahl (Häufigkeitszahl)

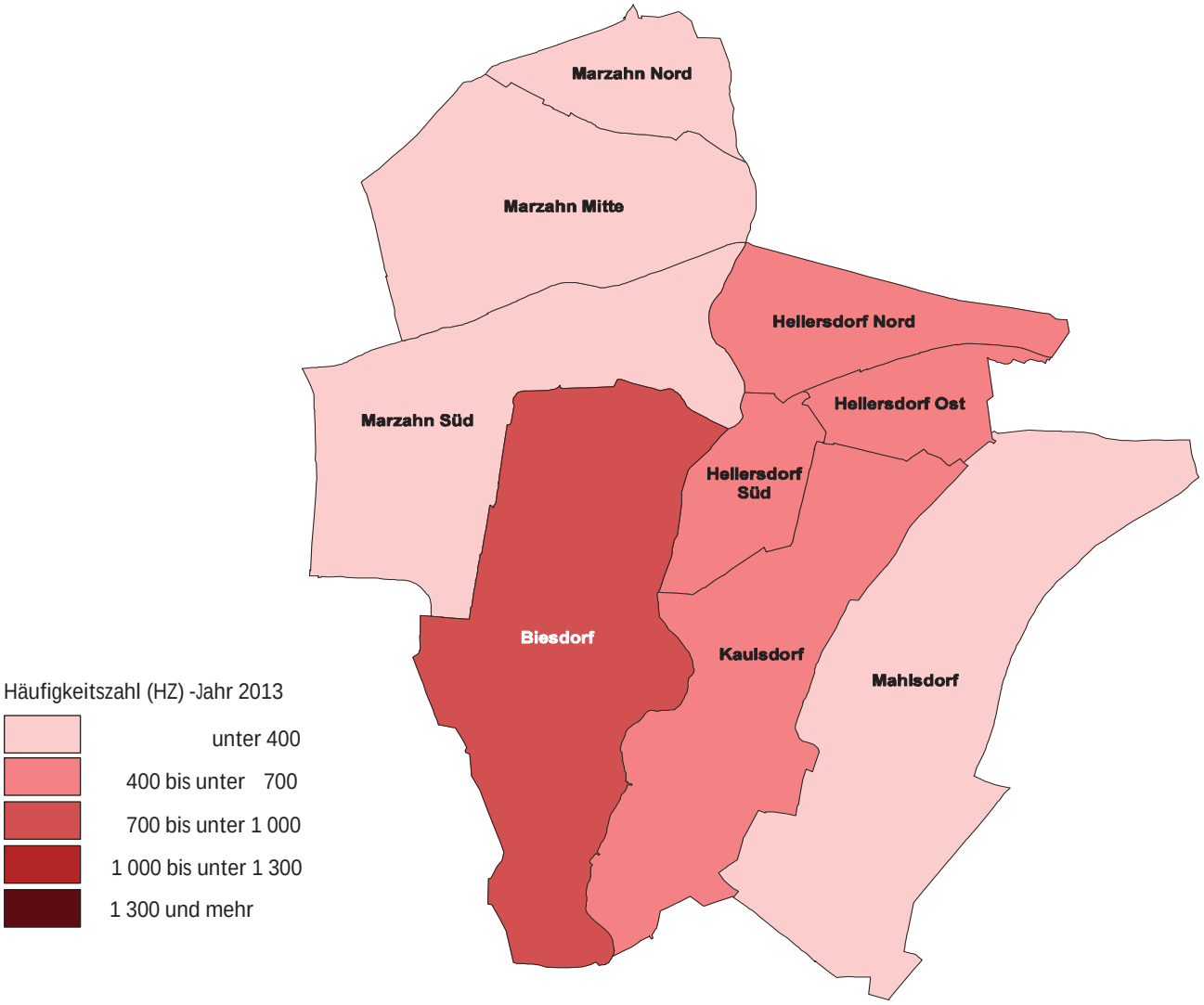

Fahrraddiebstahl (PKS-Schlüssel 3**3**, 4**3**)

Bezirksregion	Jahr 2012		Jahr 2013		Zu-/Abnahme			
	erfasste Fälle	HZ	erfasste Fälle	HZ	Fälle absolut	Fälle in %	HZ absolut	HZ in %
Marzahn Nord	97	428	88	384	- 9	x	- 44	(- 10,3)
Marzahn Mitte	145	321	147	322	2	1,4	1	0,3
Marzahn Süd	119	330	114	312	- 5	- 4,2	- 18	- 5,5
Hellersdorf Nord	133	406	169	507	36	27,1	101	24,9
Hellersdorf Ost	122	661	126	667	4	3,3	6	0,9
Hellersdorf Süd	78	322	102	418	24	x	96	(29,8)
Biesdorf	192	763	190	745	- 2	- 1,0	- 18	- 2,4
Kaulsdorf	89	476	86	461	- 3	x	- 15	(- 3,2)
Mahlsdorf	89	330	86	317	- 3	x	- 13	(- 3,9)
nicht zuzuordnen	11		6					

Bezirk Berlin Lichtenberg

Fahrraddiebstahl (Häufigkeitszahl)

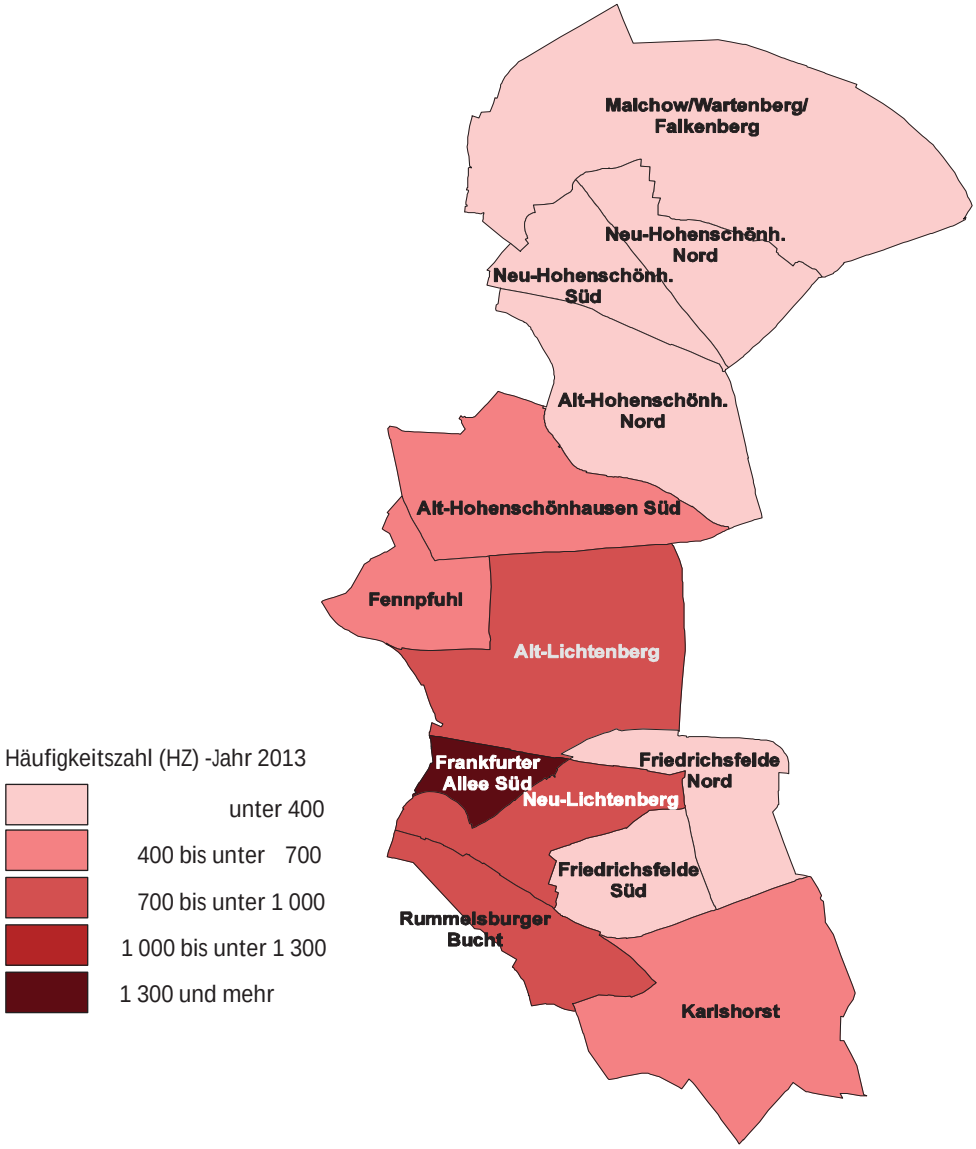

Fahrraddiebstahl (PKS-Schlüssel 3**3**, 4**3**)

Bezirksregion	Jahr 2012		Jahr 2013		Zu-/Abnahme			
	erfasste Fälle	HZ	erfasste Fälle	HZ	Fälle absolut	Fälle in %	HZ absolut	HZ in %
Malchow/Warten-/Falkenberg.....	11	262	8	188	- 3	x	- 74	(- 28,2)
Neu-Hohenschönhausen Nord.....	152	553	99	358	- 53	- 34,9	- 195	- 35,3
Neu-Hohenschönhausen Süd.....	99	383	78	302	- 21	x	- 81	(- 21,1)
Alt-Hohenschönhausen Nord.....	40	297	37	274	- 3	x	- 23	(- 7,7)
Alt-Hohenschönhausen Süd.....	146	497	151	513	5	3,4	16	3,2
Fennpfuhl.....	187	589	188	587	1	0,5	- 2	- 0,3
Alt-Lichtenberg.....	194	808	178	714	- 16	- 8,2	- 94	- 11,6
Frankfurter Allee Süd.....	111	1 149	137	1 367	26	23,4	218	19,0
Neu-Lichtenberg.....	174	593	287	955	113	64,9	362	61,0
Friedrichsfelde Nord.....	39	293	34	251	- 5	x	- 42	(- 14,3)
Friedrichsfelde Süd.....	88	365	88	358		x	- 7	(- 1,9)
Rummelsburger Bucht.....	48	1 471	25	754	- 23	x	- 717	(- 48,7)
Karlshorst.....	124	549	157	674	33	26,6	125	22,8
nicht zuzuordnen.....	5		7					

Bezirk Berlin Reinickendorf

Fahrraddiebstahl (Häufigkeitszahl)

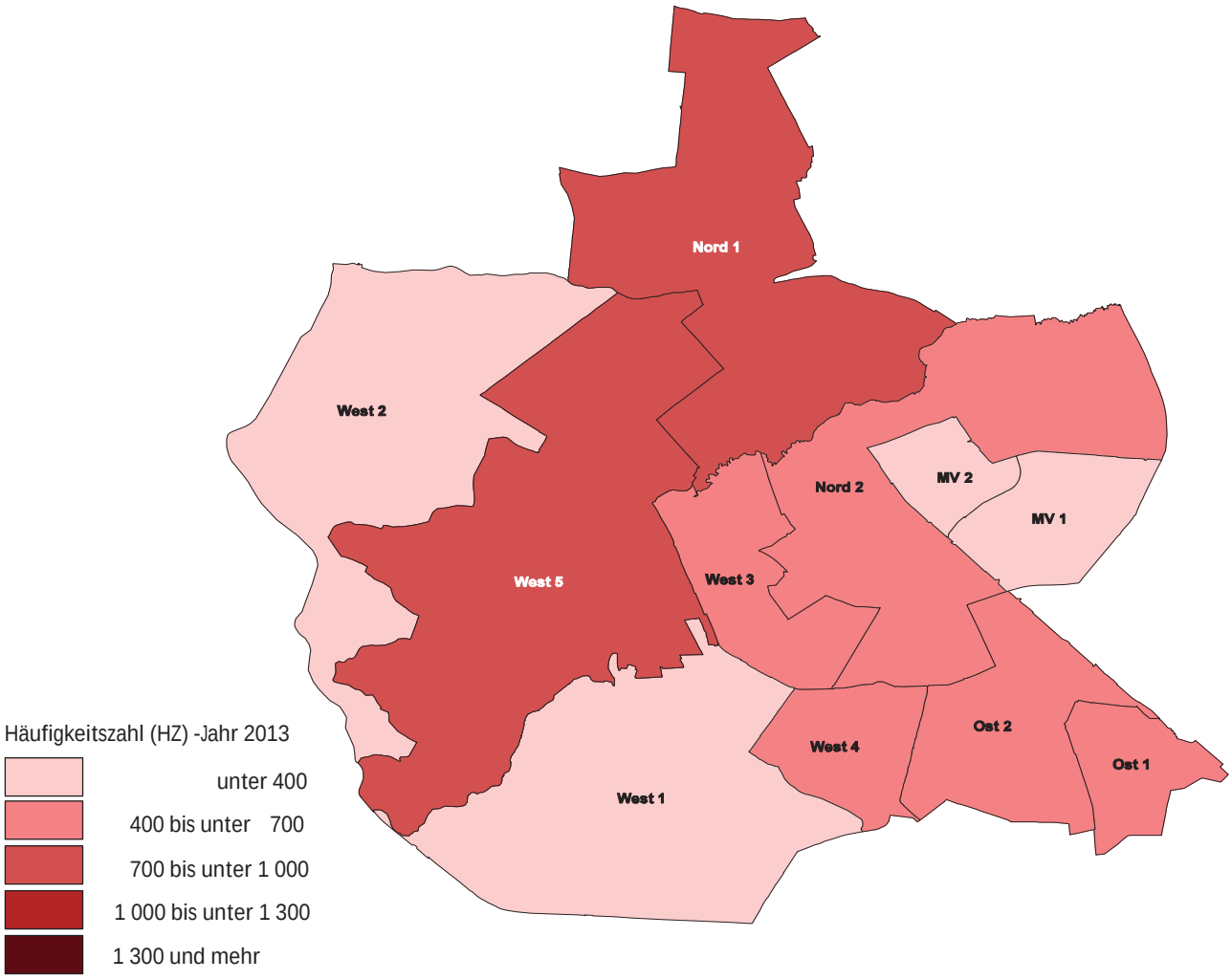

Fahrraddiebstahl (PKS-Schlüssel 3**3**, 4**3**)

Bezirksregion	Jahr 2012		Jahr 2013		Zu-/Abnahme			
	erfasste Fälle	HZ	erfasste Fälle	HZ	Fälle absolut	Fälle in %	HZ absolut	HZ in %
Ost 1	179	698	158	608	- 21	- 11,7	- 90	- 12,9
Ost 2	215	843	170	657	- 45	- 20,9	- 186	- 22,1
West 1	68	467	53	366	- 15	x	- 101	(- 21,6)
West 4	107	428	117	460	10	9,3	32	7,5
West 5	106	1 038	102	991	- 4	- 3,8	- 47	- 4,5
West 2	93	395	77	324	- 16	x	- 71	(- 18,0)
Nord 1	250	765	273	832	23	9,2	67	8,8
Nord 2	195	668	169	568	- 26	- 13,3	- 100	- 15,0
MV 1	173	488	133	366	- 40	- 23,1	- 122	- 25,0
MV 2	30	366	26	306	- 4	x	- 60	(- 16,4)
West 3	121	757	70	438	- 51	- 42,1	- 319	- 42,1
nicht zuzuordnen	3		-					

Berlin - Wohnraumeinbruch (Häufigkeitszahl)

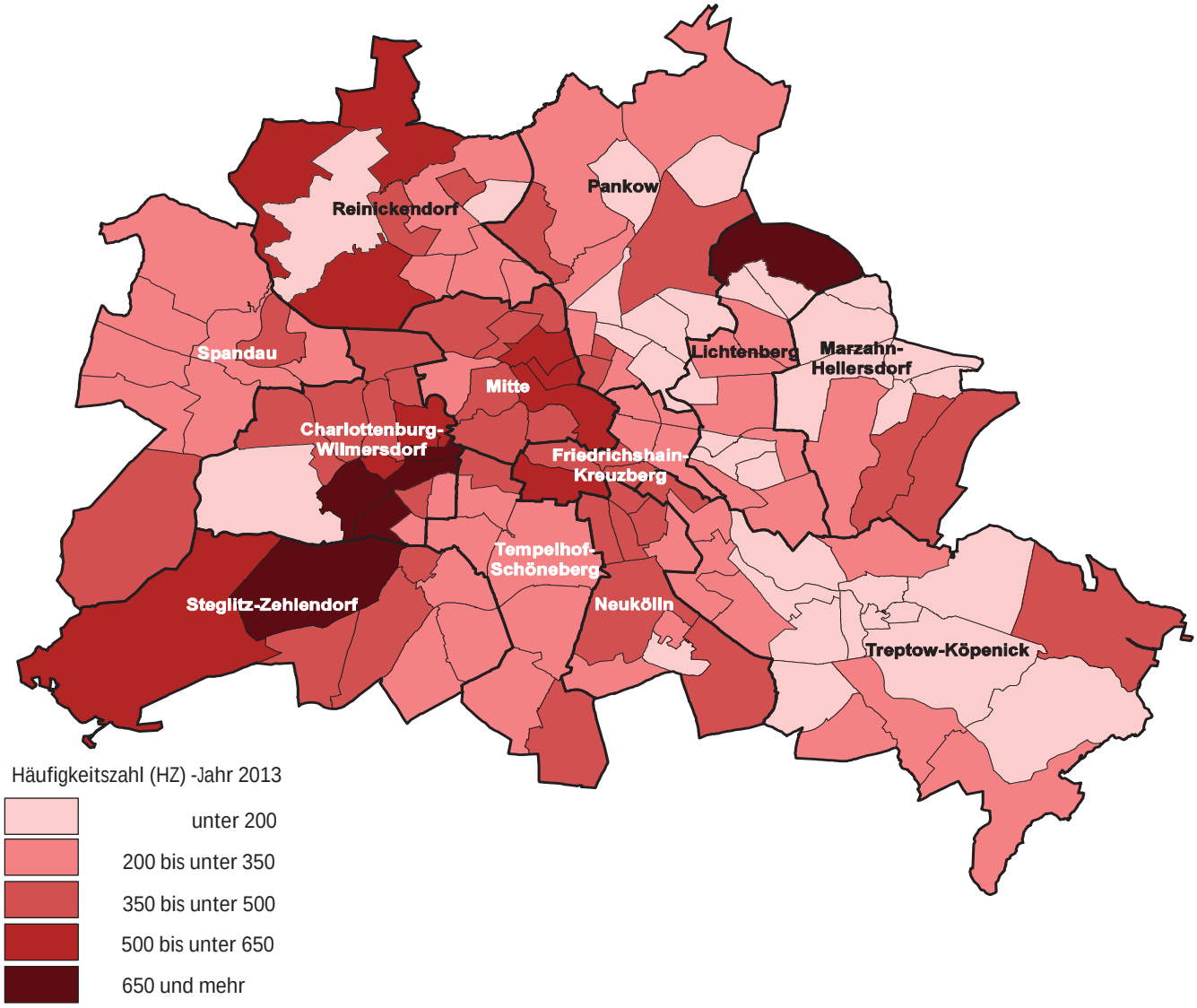

Wohnraumeinbruch (PKS-Schlüssel 435***)

Bezirk	Jahr 2012		Jahr 2013		Zu-/Abnahme			
	erfasste Fälle	HZ	erfasste Fälle	HZ	Fälle absolut	Fälle in %	HZ absolut	HZ in %
Mitte	1 695	505	1 497	436	- 198	- 11,7	- 69	- 13,7
Friedrichshain-Kreuzberg	1 214	455	1 090	402	- 124	- 10,2	- 53	- 11,6
Pankow	1 092	297	992	265	- 100	- 9,2	- 32	- 10,8
Charlottenburg-Wilmersdorf	1 544	487	1 663	518	119	7,7	31	6,4
Spandau	589	266	598	266	9	1,5	-	-
Steglitz-Zehlendorf	961	327	1 256	424	295	30,7	97	29,7
Tempelhof-Schöneberg	1 123	343	1 022	310	- 101	- 9,0	- 33	- 9,6
Neukölln	1 388	440	1 163	363	- 225	- 16,2	- 77	- 17,5
Treptow-Köpenick	605	250	451	184	- 154	- 25,5	- 66	- 26,4
Marzahn-Hellersdorf	457	183	416	164	- 41	- 9,0	- 19	- 10,4
Lichtenberg	632	245	512	195	- 120	- 19,0	- 50	- 20,4
Reinickendorf	985	400	903	362	- 82	- 8,3	- 38	- 9,5
Berlin, nicht zuzuordnen	6		3					
Berlin -Gesamt-	**12 291**	**365**	**11 566**	**340**	**- 725**	**-5,9**	**- 25**	**-6,8**

Bezirk Berlin Mitte

Wohnraumeinbruch (Häufigkeitszahl)

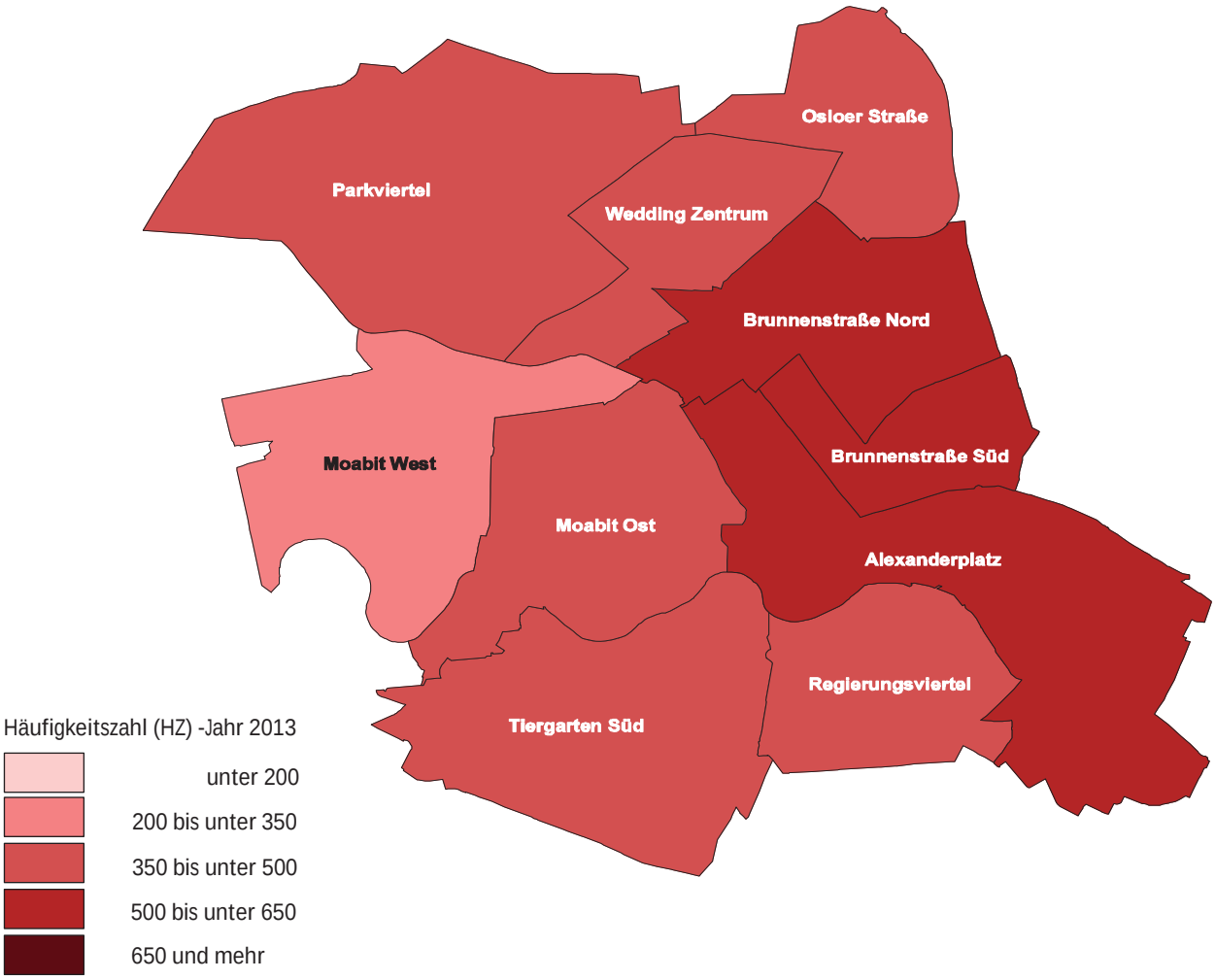

Wohnraumeinbruch (PKS-Schlüssel 435***)

Bezirksregion	Jahr 2012		Jahr 2013		Zu-/Abnahme			
	erfasste Fälle	HZ	erfasste Fälle	HZ	Fälle absolut	Fälle in %	HZ absolut	HZ in %
Tiergarten Süd	68	540	62	477	- 6	x	- 63	(- 11,7)
Regierungsviertel	37	404	33	355	- 4	x	- 49	(-12,1)
Alexanderplatz	275	583	281	584	6	2,2	1	0,2
Brunnenstraße Süd	131	512	137	516	6	4,6	4	0,8
Moabit West	161	384	139	325	- 22	- 13,7	- 59	- 15,4
Moabit Ost	90	258	128	362	38	x	104	(40,3)
Osloer Straße	226	645	166	459	- 60	- 26,5	- 186	- 28,8
Brunnenstraße Nord	252	714	196	547	- 56	- 22,2	- 167	- 23,4
Parkviertel	157	379	154	364	- 3	- 1,9	- 15	- 4,0
Wedding Zentrum	298	567	201	371	- 97	- 32,6	- 196	- 34,6
nicht zuzuordnen		-		-				

Bezirk Berlin Friedrichshain-Kreuzberg

Wohnraumeinbruch (Häufigkeitszahl)

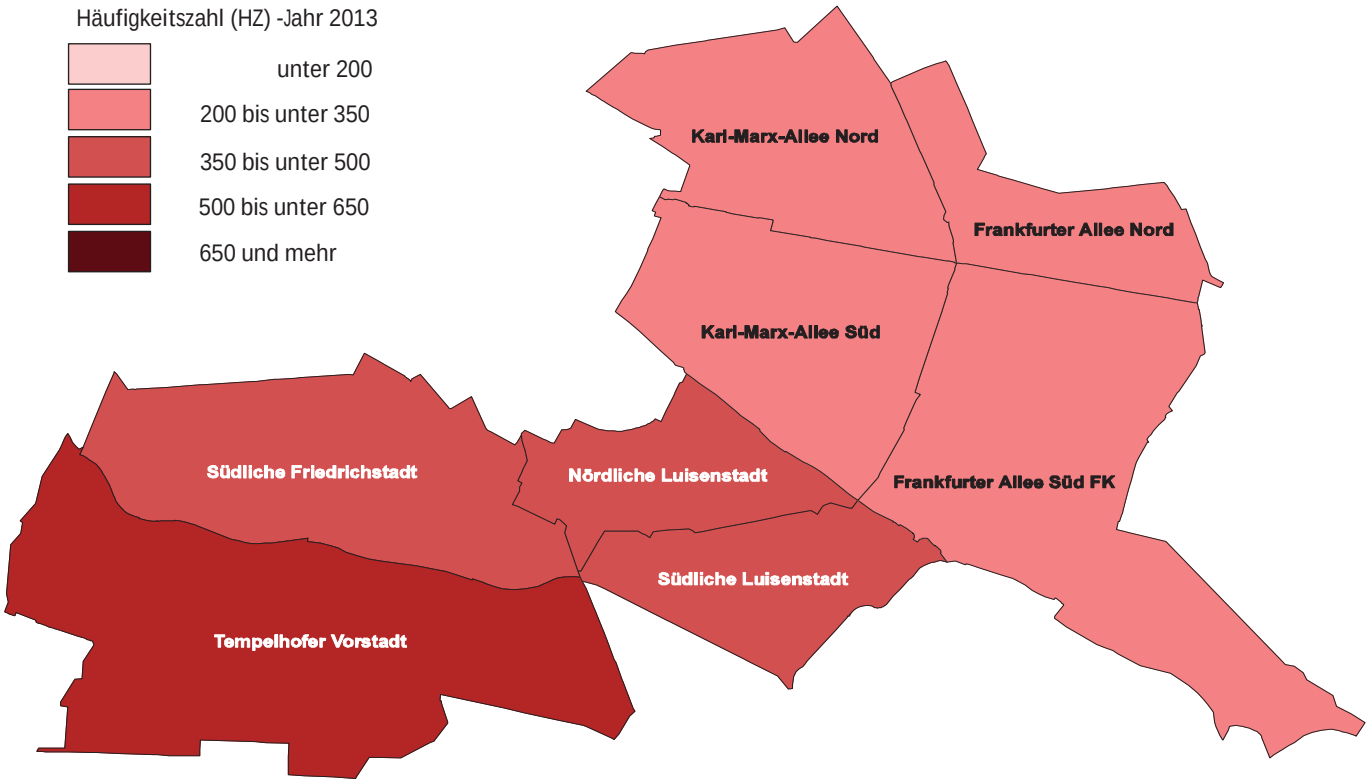

Wohnraumeinbruch (PKS-Schlüssel 435***)

Bezirksregion	Jahr 2012		Jahr 2013		Zu-/Abnahme			
	erfasste Fälle	HZ	erfasste Fälle	HZ	Fälle absolut	Fälle in %	HZ absolut	HZ in %
Südliche Friedrichstadt.....	219	562	186	471	- 33	- 15,1	- 91	- 16,2
Tempelhofer Vorstadt.....	390	640	338	546	- 52	- 13,3	- 94	- 14,7
Nördliche Luisenstadt.....	115	515	103	457	- 12	- 10,4	- 58	- 11,3
Südliche Luisenstadt.....	150	575	119	450	- 31	- 20,7	- 125	- 21,7
Karl-Marx-Allee Nord.....	56	252	56	249		x	- 3	(- 1,2)
Karl-Marx-Allee Süd.....	59	257	68	290	9	x	33	(12,8)
Frankfurter Allee Nord.....	59	217	76	275	17	x	58	(26,7)
Frankfurter Allee Süd FK.....	166	359	144	305	- 22	- 13,3	- 54	- 15,0
nicht zuzuordnen.....								

Bezirk Berlin Pankow

Wohnraumeinbruch (Häufigkeitszahl)

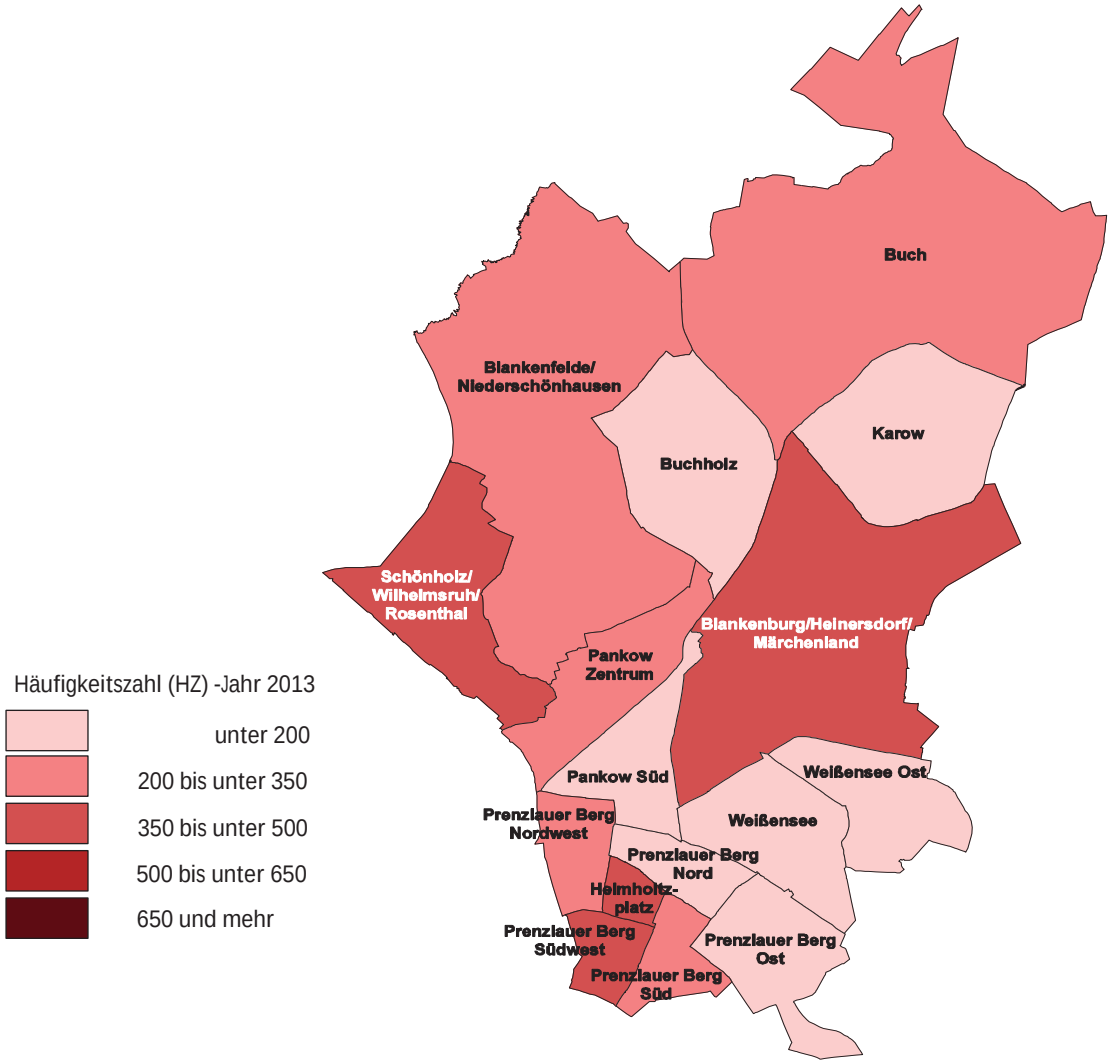

Wohnraumeinbruch (PKS-Schlüssel 435***)

Bezirksregion	Jahr 2012		Jahr 2013		Zu-/Abnahme			
	erfasste Fälle	HZ	erfasste Fälle	HZ	Fälle absolut	Fälle in %	HZ absolut	HZ in %
Buch	21	161	29	214	8	x	53	(32,9)
Blankenfelde/Niederschönhausen	69	273	62	239	- 7	x	- 34	(- 12,5)
Buchholz	38	226	23	135	- 15	x	- 91	(- 40,3)
Karow	19	102	36	193	17	x	91	(89,2)
Blankenburg/Heinersdorf	55	389	63	446	8	x	57	(14,7)
Pankow Süd	50	157	59	182	9	x	25	(15,9)
Schönholz/Wilhelmsruh/Rosenthal	82	479	67	390	- 15	x	- 89	(- 18,6)
Pankow Zentrum	61	188	102	306	41	x	118	(62,8)
Weißensee	93	282	63	187	- 30	x	- 95	(- 33,7)
Weißensee Ost	23	153	26	172	3	x	19	(12,4)
Prenzlauer Berg Nordwest	78	330	67	276	- 11	x	- 54	(- 16,4)
Prenzlauer Berg Nord	67	260	52	199	- 15	x	- 61	(- 23,5)
Helmholtzplatz	99	467	90	415	- 9	x	- 52	(- 11,1)
Prenzlauer Berg Ost	61	251	43	173	- 18	x	- 78	(- 31,1)
Prenzlauer Berg Südwest	149	615	118	476	- 31	- 20,8	- 139	- 22,6
Prenzlauer Berg Süd	127	412	87	279	- 40	- 31,5	- 133	- 32,3
nicht zuzuordnen			5					

Bezirk Berlin Charlottenburg-Wilmersdorf

Wohnraumeinbruch (Häufigkeitszahl)

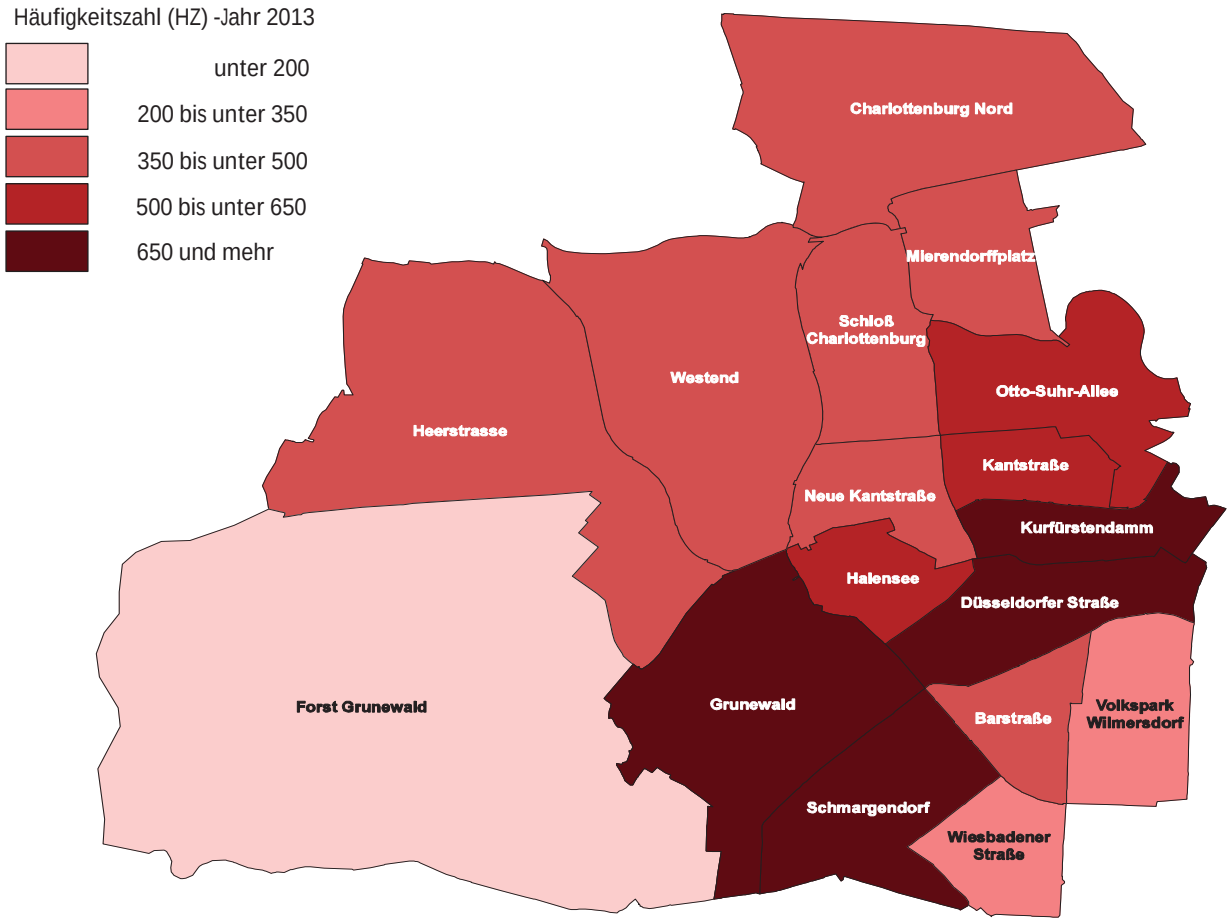

Wohnraumeinbruch (PKS-Schlüssel 435***)

Bezirksregion	Jahr 2012		Jahr 2013		Zu-/Abnahme			
	erfasste Fälle	HZ	erfasste Fälle	HZ	Fälle absolut	Fälle in %	HZ absolut	HZ in %
Charlottenburg Nord.....	99	547	79	428	- 20	x	- 119	(- 21,8)
Heerstraße.....	51	408	62	492	11	x	84	(20,6)
Westend.....	112	428	110	413	- 2	- 1,8	- 15	- 3,5
Schloß Charlottenburg.....	88	380	92	393	4	x	13	(3,4)
Mierendorffplatz.....	38	267	57	391	19	x	124	(46,4)
Otto-Suhr-Allee.....	113	444	157	609	44	38,9	165	37,2
Neue Kantstraße.....	105	458	108	466	3	2,9	8	1,7
Kantstraße.....	116	567	119	574	3	2,6	7	1,2
Kurfürstendamm.....	94	646	106	727	12	x	81	(12,5)
Halensee.....	77	542	85	589	8	x	47	(8,7)
Grunewald.....	194	1 084	164	900	- 30	- 15,5	- 184	- 17,0
Schmargendorf.....	86	623	111	798	25	x	175	(28,1)
Wiesbadener Straße.....	54	300	55	304	1	x	4	(1,3)
Düsseldorfer Straße.....	158	539	194	652	36	22,8	113	21,0
Barstraße.....	44	326	64	472	20	x	146	(44,8)
Volkspark Wilmersdorf.....	114	352	100	305	- 14	- 12,3	- 47	- 13,4
Forst Grunewald.....						x		
nicht zuzuordnen.....	1							

Bezirk Berlin Spandau

Wohnraumeinbruch (Häufigkeitszahl)

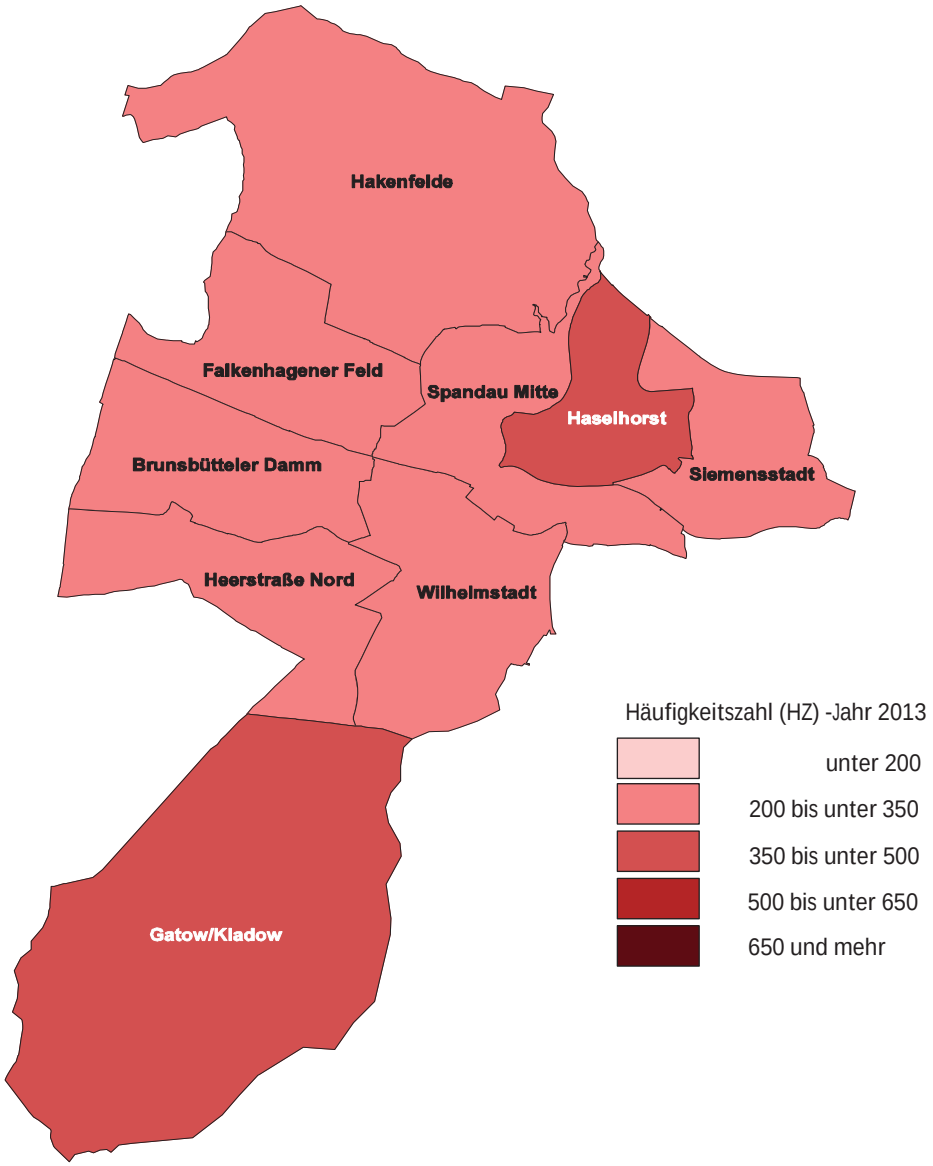

Wohnraumeinbruch (PKS-Schlüssel 435***)

Bezirksregion	Jahr 2012		Jahr 2013		Zu-/Abnahme			
	erfasste Fälle	HZ	erfasste Fälle	HZ	Fälle absolut	Fälle in %	HZ absolut	HZ in %
Hakenfelde.....	54	238	52	229	- 2	x	- 9	(- 3,8)
Falkenhagener Feld.....	73	187	89	227	16	x	40	(21,4)
Spandau Mitte.....	68	207	72	214	4	x	7	(3,4)
Brunsbütteler Damm.....	47	203	58	251	11	x	48	(23,6)
Heerstraße Nord.....	91	341	71	265	- 20	x	- 76	(- 22,3)
Wilhelmstadt.....	100	295	92	268	- 8	- 8,0	- 27	- 9,2
Haselhorst.....	52	378	53	367	1	x	- 11	(- 2,9)
Siemensstadt.....	39	336	30	250	- 9	x	- 86	(- 25,6)
Gatow/Kladow.....	65	366	80	441	15	x	75	(20,5)
nicht zuzuordnen.....			1					

Bezirk Berlin Steglitz-Zehlendorf

Wohnraumeinbruch (Häufigkeitszahl)

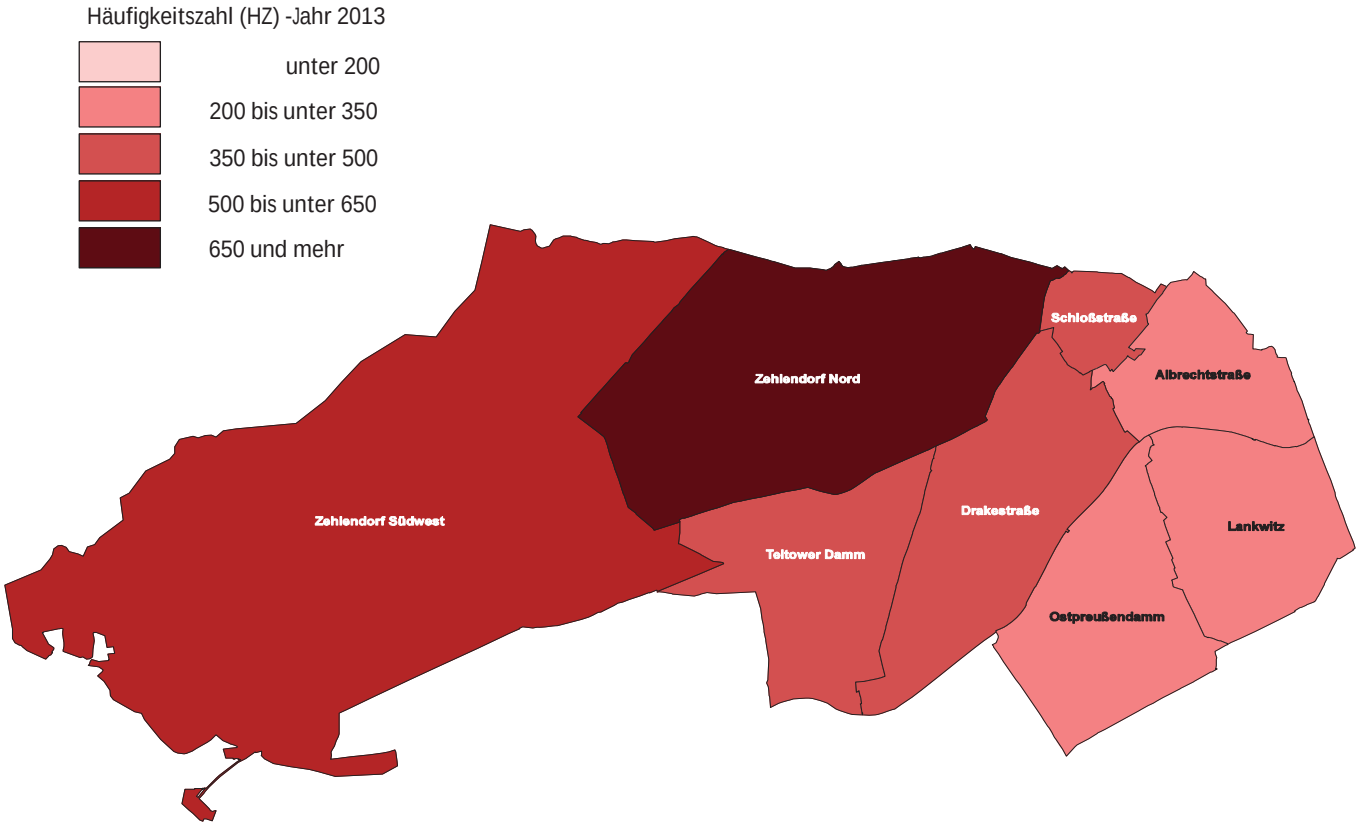

Wohnraumeinbruch (PKS-Schlüssel 435***)

Bezirksregion	Jahr 2012		Jahr 2013		Zu-/Abnahme			
	erfasste Fälle	HZ	erfasste Fälle	HZ	Fälle		HZ	
					absolut	in %	absolut	in %
Schloßstraße.....	79	369	107	495	28	x	126	(34,1)
Albrechtstraße.....	136	265	162	313	26	19,1	48	18,1
Lankwitz.....	89	215	137	328	48	x	113	(52,6)
Ostpreußendamm.....	96	277	89	254	- 7	x	- 23	(- 8,3)
Teltower Damm.....	103	315	148	452	45	43,7	137	43,5
Drakestraße.....	136	298	166	357	30	22,1	59	19,8
Zehlendorf Südwest.....	113	443	155	607	42	37,2	164	37,0
Zehlendorf Nord.....	208	501	292	703	84	40,4	202	40,3
nicht zuzuordnen.....	1							

Bezirk Berlin Tempelhof-Schöneberg

Wohnraumeinbruch (Häufigkeitszahl)

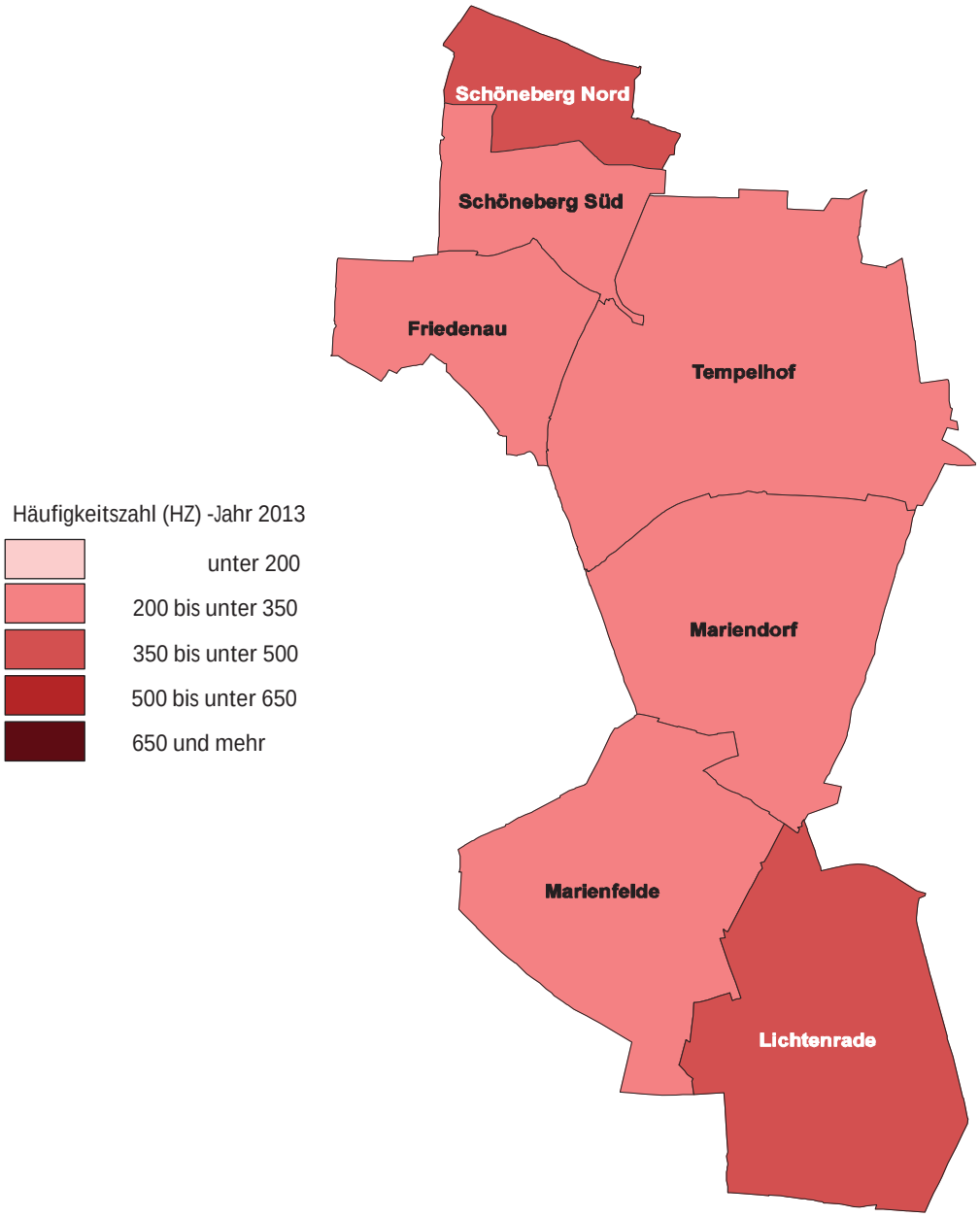

Wohnraumeinbruch (PKS-Schlüssel 435***)

Bezirksregion	Jahr 2012		Jahr 2013		Zu-/Abnahme			
	erfasste Fälle	HZ	erfasste Fälle	HZ	Fälle absolut	Fälle in %	HZ absolut	HZ in %
Schöneberg Nord.....	292	620	233	496	- 59	- 20,2	- 124	- 20,0
Schöneberg Süd.....	219	461	162	340	- 57	- 26,0	- 121	- 26,2
Friedenau.....	122	277	89	200	- 33	- 27,0	- 77	- 27,8
Tempelhof.....	159	270	145	242	- 14	- 8,8	- 28	- 10,4
Mariendorf.....	131	263	145	290	14	10,7	27	10,3
Marienfelde.....	52	171	68	223	16	x	52	(30,4)
Lichtenrade.....	148	299	179	360	31	20,9	61	20,4
nicht zuzuordnen.....			1					

Bezirk Berlin Neukölln

Wohnraumeinbruch (Häufigkeitszahl)

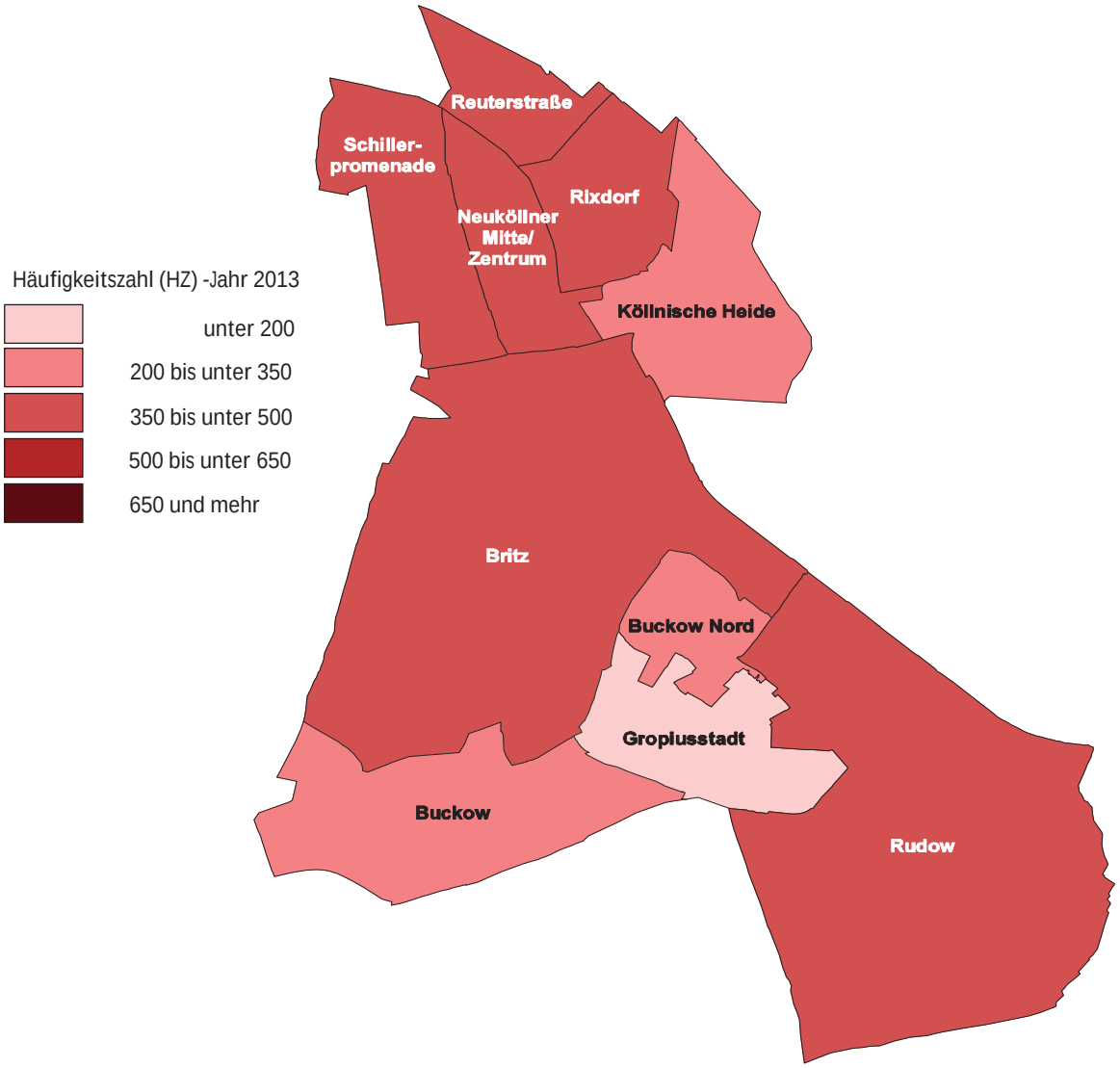

Wohnraumeinbruch (PKS-Schlüssel 435***)

Bezirksregion	Jahr 2012		Jahr 2013		Zu-/Abnahme			
	erfasste Fälle	HZ	erfasste Fälle	HZ	Fälle absolut	Fälle in %	HZ absolut	HZ in %
Schillerpromenade.....	150	485	140	444	- 10	- 6,7	- 41	- 8,5
Neuköllner Mitte/Zentrum.....	201	545	175	464	- 26	- 12,9	- 81	- 14,9
Reuterstraße.....	245	631	151	380	- 94	- 38,4	- 251	- 39,8
Rixdorf.....	201	517	148	374	- 53	- 26,4	- 143	- 27,7
Köllnische Heide.....	60	407	44	293	- 16	x	- 114	(- 28,0)
Britz.....	175	432	159	387	- 16	- 9,1	- 45	- 10,4
Buckow.....	62	225	93	334	31	x	109	(48,4)
Gropiusstadt.....	67	186	72	198	5	x	12	(6,5)
Buckow Nord.....	46	495	28	299	- 18	x	- 196	(- 39,6)
Rudow.....	181	432	153	363	- 28	- 15,5	- 69	- 16,0
nicht zuzuordnen.....								

Bezirk Berlin Treptow-Köpenick

Wohnraumeinbruch (Häufigkeitszahl)

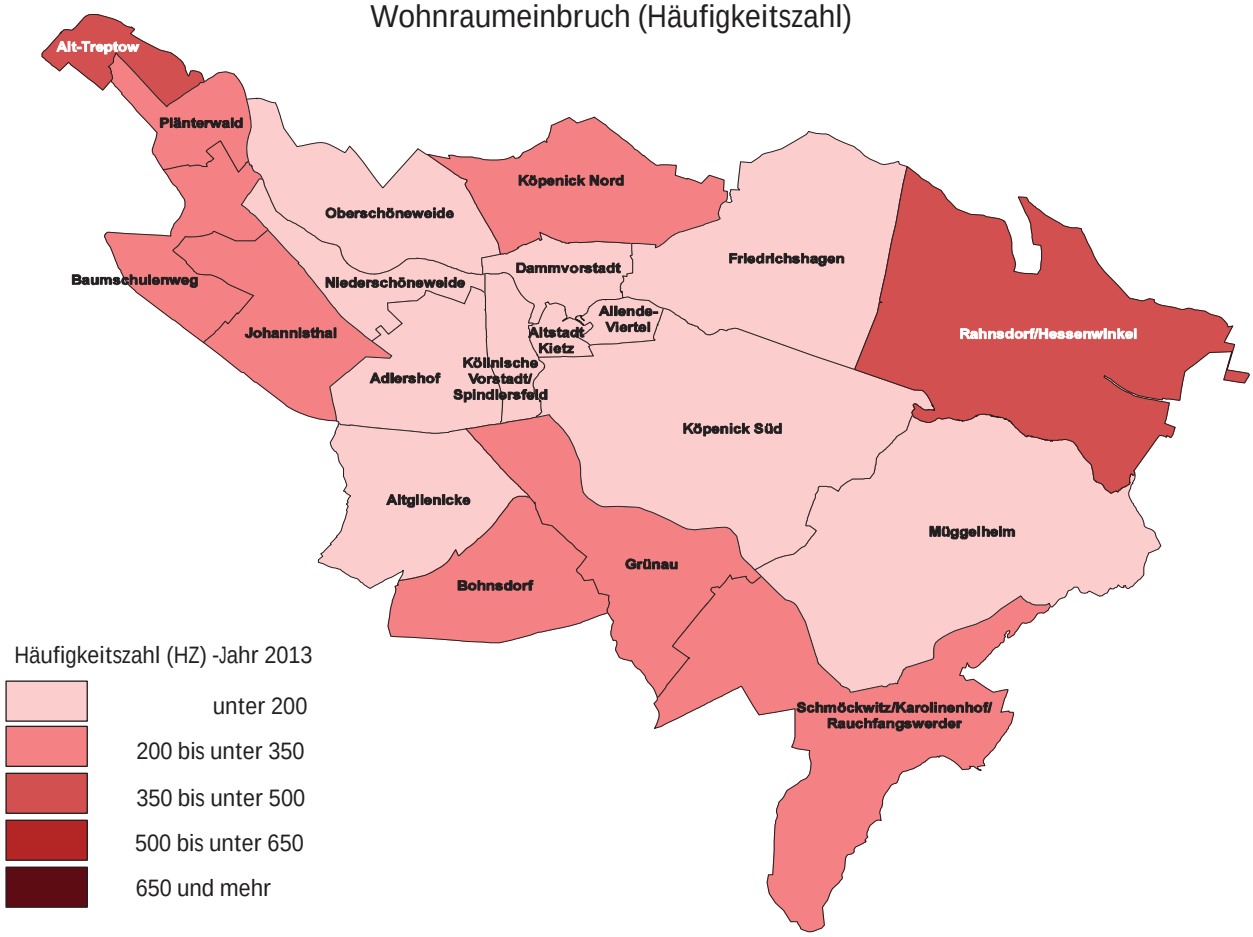

Wohnraumeinbruch (PKS-Schlüssel 435***)

Bezirksregion	Jahr 2012		Jahr 2013		Zu-/Abnahme			
	erfasste Fälle	HZ	erfasste Fälle	HZ	Fälle absolut	Fälle in %	HZ absolut	HZ in %
Alt-Treptow	53	485	42	378	- 11	x	- 107	(- 22,1)
Plänterwald	34	315	32	295	- 2	x	- 20	(- 6,3)
Baumschulenweg	74	429	47	270	- 27	x	- 159	(- 37,1)
Johannisthal	48	262	45	244	- 3	x	- 18	(- 6,9)
Oberschöneweide	51	266	27	137	- 24	x	- 129	(- 48,5)
Niederschöneweide	19	182	10	94	- 9	x	- 88	(- 48,4)
Adlershof	34	221	18	115	- 16	x	- 106	(- 48,0)
Kölln. Vorstadt/Spindlersf.	14	142	13	130	- 1	x	- 12	(- 8,5)
Altglienicke	71	278	46	178	- 25	x	- 100	(- 36,0)
Bohnsdorf	27	227	28	232	1	x	5	(2,2)
Grünau	21	389	15	268	- 6	x	- 121	(- 31,1)
Schmöckwitz/Karolinenhof	14	345	13	323	- 1	x	- 22	(- 6,4)
Köpenick Süd	12	77	10	64	- 2	x	- 13	x
Allende-Viertel	3	49	2	33	- 1	x	- 16	x
Altstadt Kietz	5	73	9	130	4	x	57	x
Müggelheim	8	123	6	92	- 2	x	- 31	(- 25,2)
Friedrichshagen	28	160	13	74	- 15	x	- 86	(- 53,8)
Rahnsdorf/Hessenwinkel	44	491	37	413	- 7	x	- 78	(- 15,9)
Dammvorstadt	12	127	10	105	- 2	x	- 22	(- 17,3)
Köpenick Nord	33	268	27	220	- 6	x	- 48	(- 17,9)
nicht zuzuordnen			1					

Bezirk Berlin Marzahn-Hellersdorf

Wohnraumeinbruch (Häufigkeitszahl)

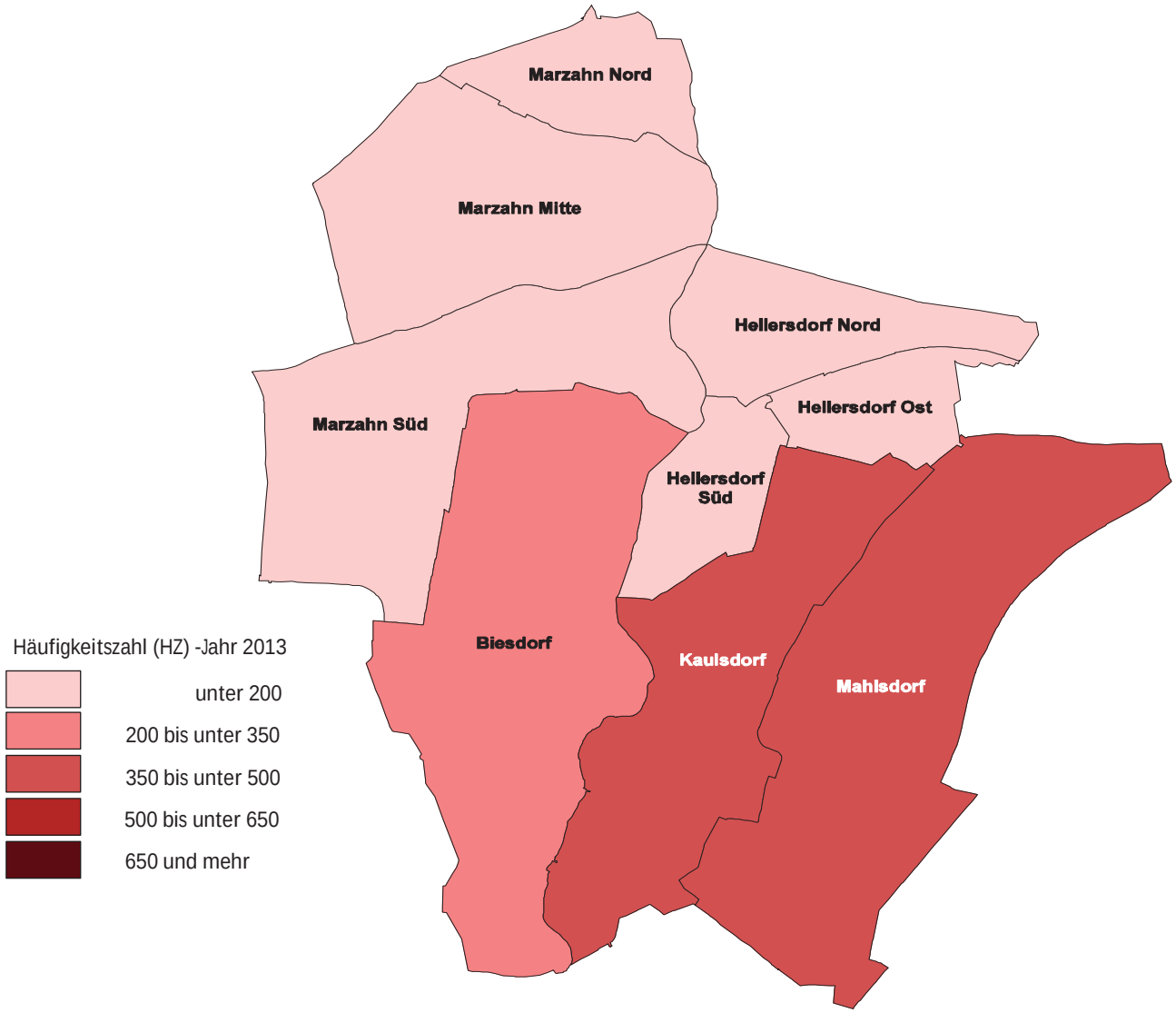

Wohnraumeinbruch (PKS-Schlüssel 435***)

Bezirksregion	Jahr 2012		Jahr 2013		Zu-/Abnahme			
	erfasste Fälle	HZ	erfasste Fälle	HZ	Fälle		HZ	
					absolut	in %	absolut	in %
Marzahn Nord	31	137	30	131	- 1	x	- 6	(- 4,4)
Marzahn Mitte	50	111	43	94	- 7	x	- 17	(- 15,3)
Marzahn Süd	41	114	37	101	- 4	x	- 13	(- 11,4)
Hellersdorf Nord	28	85	23	69	- 5	x	- 16	x
Hellersdorf Ost	10	54	14	74	4	x	20	x
Hellersdorf Süd	26	107	20	82	- 6	x	- 25	(- 23,4)
Biesdorf	97	386	55	216	- 42	x	- 170	(- 44,0)
Kaulsdorf	77	412	82	440	5	x	28	(6,8)
Mahlsdorf	97	359	112	413	15	x	54	(15,0)
nicht zuzuordnen								

Bezirk Berlin Lichtenberg

Wohnraumeinbruch (Häufigkeitszahl)

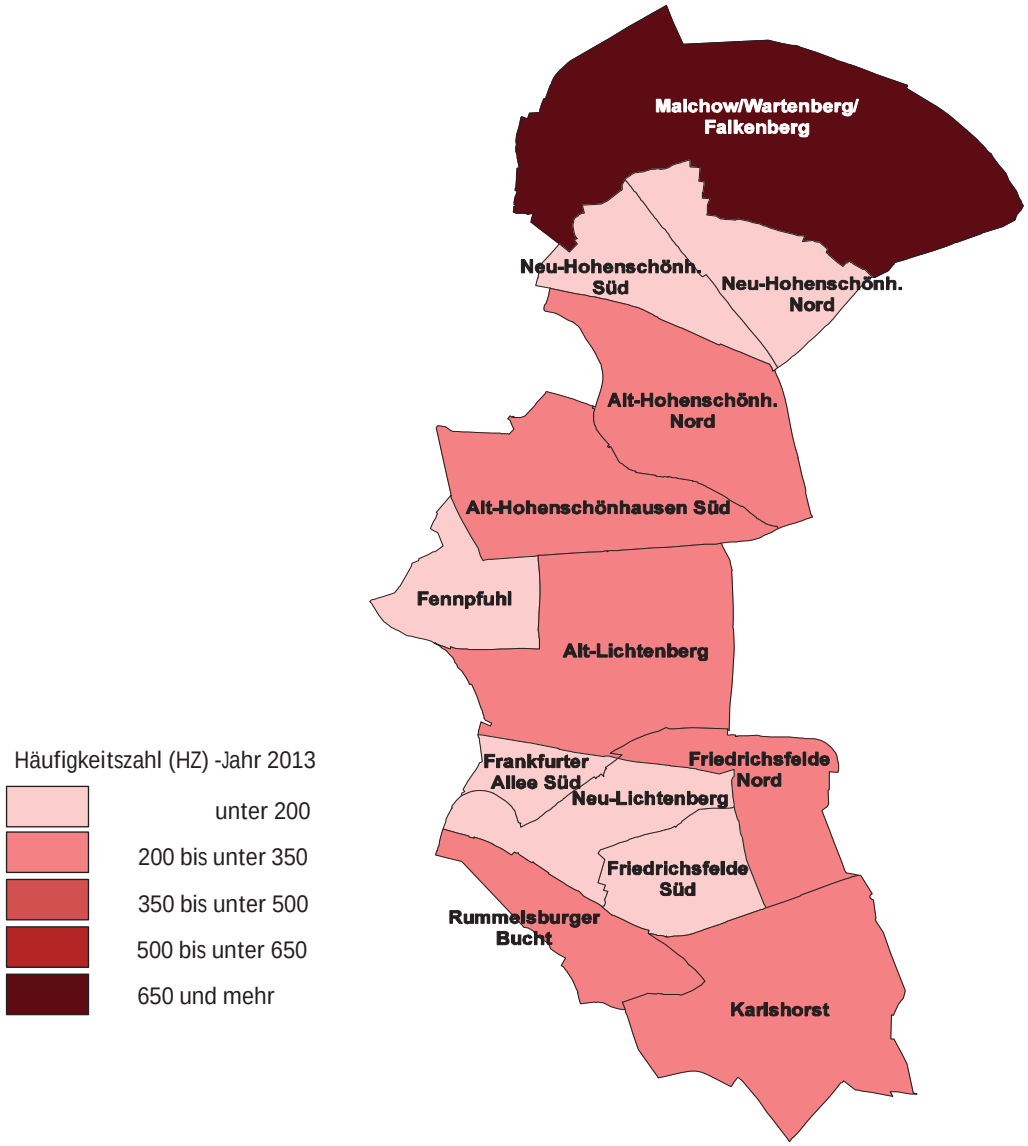

Wohnraumeinbruch (PKS-Schlüssel 435***)

Bezirksregion	Jahr 2012		Jahr 2013		Zu-/Abnahme			
	erfasste Fälle	HZ	erfasste Fälle	HZ	Fälle absolut	Fälle in %	HZ absolut	HZ in %
Malchow/Warten-/Falkenberg.....	10	239	35	824	25	x	585	(244,8)
Neu-Hohenschönhausen Nord.....	19	69	18	65	- 1	x	- 4	x
Neu-Hohenschönhausen Süd.....	30	116	40	155	10	x	39	(33,6)
Alt-Hohenschönhausen Nord.....	59	438	44	326	- 15	x	- 112	(- 25,6)
Alt-Hohenschönhausen Süd.....	70	238	66	224	- 4	x	- 14	(- 5,9)
Fennpfuhl.....	89	281	44	137	- 45	x	- 144	(- 51,2)
Alt-Lichtenberg.....	76	316	52	209	- 24	x	- 107	(- 33,9)
Frankfurter Allee Süd.....	25	259	16	160	- 9	x	- 99	(- 38,2)
Neu-Lichtenberg.....	83	283	30	100	- 53	x	- 183	(- 64,7)
Friedrichsfelde Nord.....	38	285	39	288	1	x	3	(1,1)
Friedrichsfelde Süd.....	60	249	49	199	- 11	x	- 50	(- 20,1)
Rummelsburger Bucht.....	7	215	9	271	2	x	56	(26,0)
Karlshorst.....	63	279	70	300	7	x	21	(7,5)
nicht zuzuordnen.....	3							

Bezirk Berlin Reinickendorf

Wohnraumeinbruch (Häufigkeitszahl)

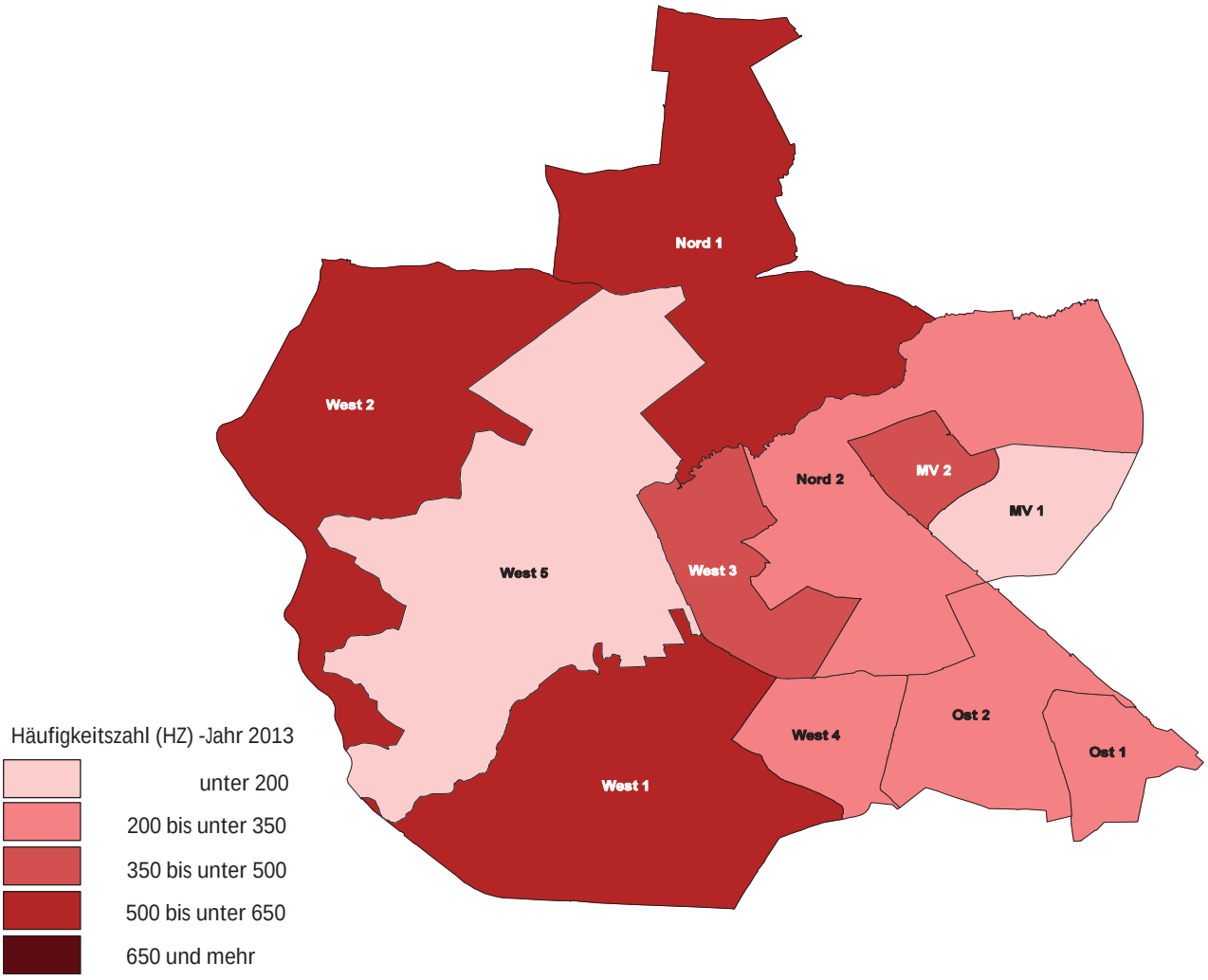

Wohnraumeinbruch (PKS-Schlüssel 435***)

Bezirksregion	Jahr 2012		Jahr 2013		Zu-/Abnahme			
	erfasste Fälle	HZ	erfasste Fälle	HZ	Fälle absolut	Fälle in %	HZ absolut	HZ in %
Ost 1	110	429	80	308	- 30	- 27,3	- 121	- 28,2
Ost 2	79	310	60	232	- 19	x	- 78	(- 25,2)
West 1	105	722	76	525	- 29	- 27,6	- 197	- 27,3
West 4	103	412	67	264	- 36	- 35,0	- 148	- 35,9
West 5	32	313	19	185	- 13	x	- 128	(- 40,9)
West 2	96	407	129	543	33	x	136	(33,4)
Nord 1	155	474	205	625	50	32,3	151	31,9
Nord 2	110	377	99	333	- 11	- 10,0	- 44	- 11,7
MV 1	99	280	67	184	- 32	x	- 96	(- 34,3)
MV 2	29	354	36	423	7	x	69	(19,5)
West 3	67	419	64	400	- 3	x	- 19	(- 4,5)
nicht zuzuordnen			1					

Berlin - Branddelikte -insgesamt (Häufigkeitszahl)

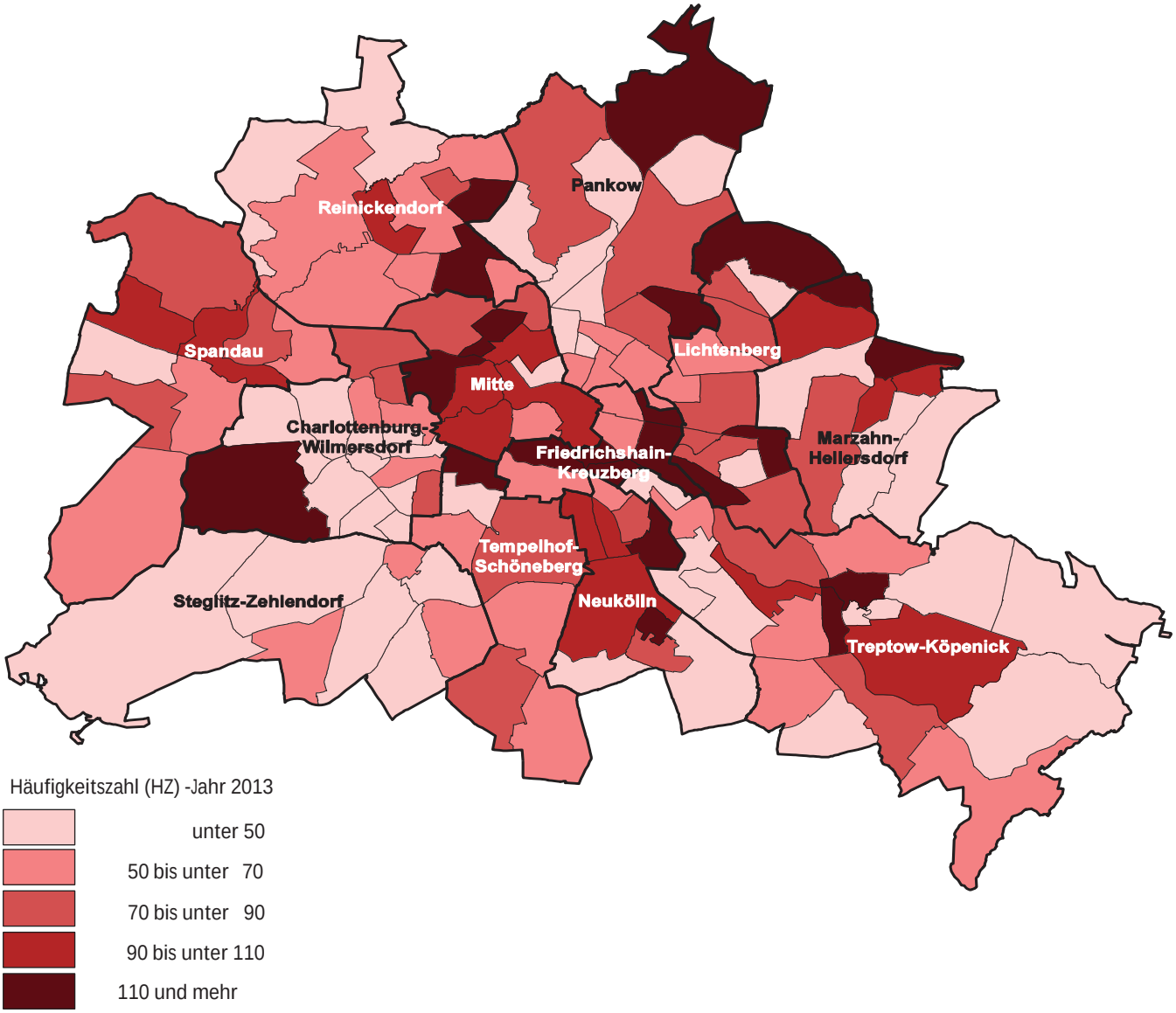

Branddelikte -insgesamt- (PKS-Schlüssel 640000, 674**2)

Bezirk	Jahr 2012		Jahr 2013		Zu-/Abnahme			
	erfasste Fälle	HZ	erfasste Fälle	HZ	Fälle absolut	Fälle in %	HZ absolut	HZ in %
Mitte	354	105	328	95	- 26	- 7,3	- 10	- 9,5
Friedrichshain-Kreuzberg	314	118	265	98	- 49	- 15,6	- 20	- 16,9
Pankow	207	56	233	62	26	12,6	6	10,7
Charlottenburg-Wilmersdorf	133	42	149	46	16	12,0	4	9,5
Spandau	175	79	174	78	- 1	- 0,6	- 1	- 1,3
Steglitz-Zehlendorf	115	39	127	43	12	10,4	4	10,3
Tempelhof-Schöneberg	208	64	232	70	24	11,5	6	9,4
Neukölln	242	77	251	78	9	3,7	1	1,3
Treptow-Köpenick	144	59	171	70	27	18,8	11	18,6
Marzahn-Hellersdorf	242	97	240	95	- 2	- 0,8	- 2	- 2,1
Lichtenberg	187	72	209	80	22	11,8	8	11,1
Reinickendorf	193	78	182	73	- 11	- 5,7	- 5	- 6,4
Berlin, nicht zuzuordnen	9		4					
Berlin -Gesamt-	**2 523**	**75**	**2 565**	**75**	**42**	**1,7**	**1**	**0,7**

Bezirk Berlin Mitte

Branddelikte -insgesamt (Häufigkeitszahl)

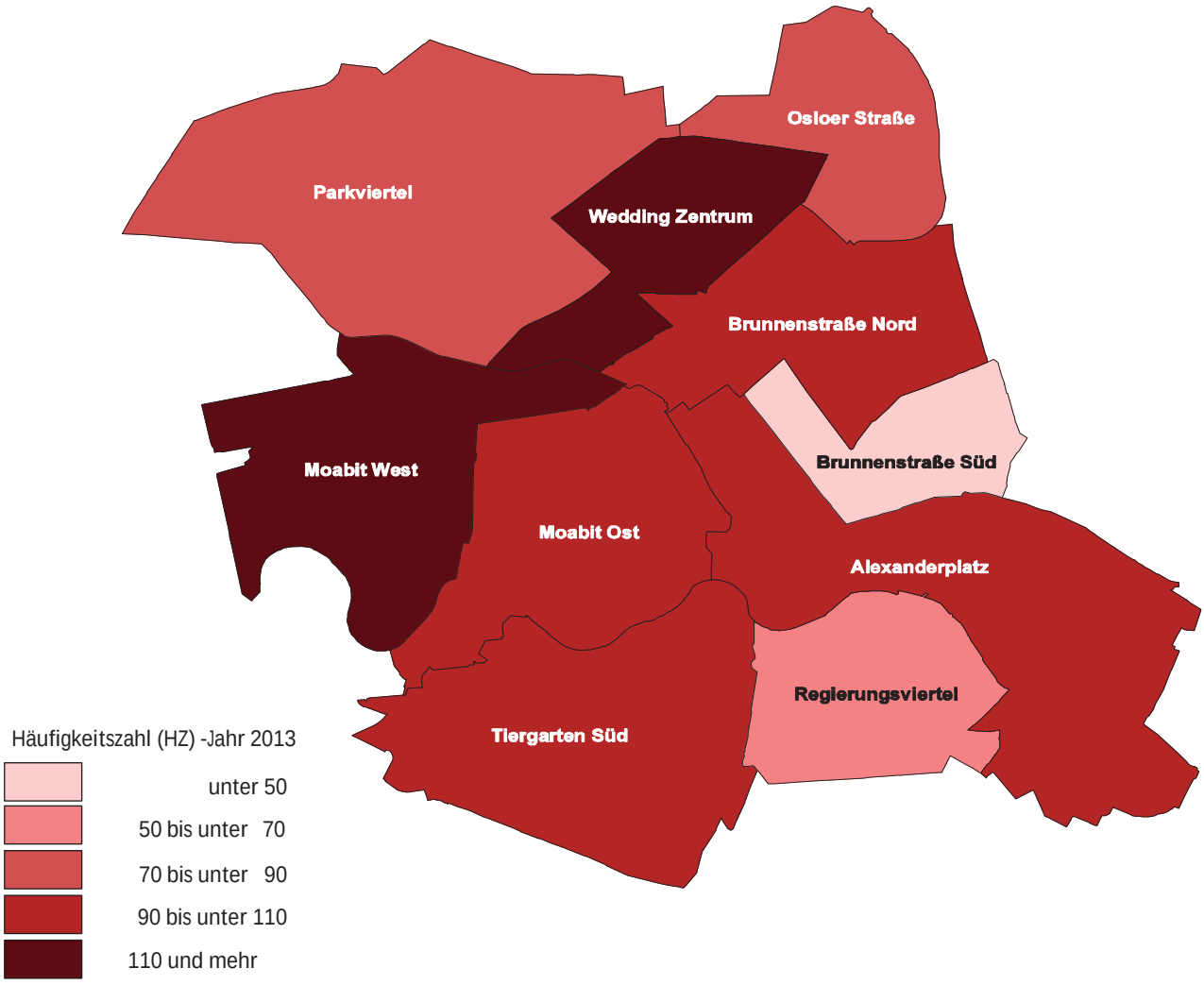

Branddelikte -insgesamt- (PKS-Schlüssel 640000, 674**2)

Bezirksregion	Jahr 2012		Jahr 2013		Zu-/Abnahme			
	erfasste Fälle	HZ	erfasste Fälle	HZ	Fälle absolut	Fälle in %	HZ absolut	HZ in %
Tiergarten Süd.....	16	127	14	108	- 2	x	- 19	(- 15,0)
Regierungsviertel.....	10	109	5	54	- 5	x	- 55	(-50,5)
Alexanderplatz.....	49	104	47	98	- 2	x	- 6	(-5,8)
Brunnenstraße Süd.....	14	55	8	30	- 6	x	- 25	x
Moabit West.....	42	100	47	110	5	x	10	(10,0)
Moabit Ost.....	33	95	35	99	2	x	4	x
Osloer Straße.....	40	114	28	77	- 12	x	- 37	(-32,5)
Brunnenstraße Nord.....	36	102	36	100		x	- 2	(-2,0)
Parkviertel.....	55	133	32	76	- 23	x	- 57	(-42,9)
Wedding Zentrum.....	54	103	70	129	16	x	26	(25,2)
nicht zuzuordnen.....	5	-	6	-				

Bezirk Berlin Friedrichshain-Kreuzberg

Branddelikte -insgesamt (Häufigkeitszahl)

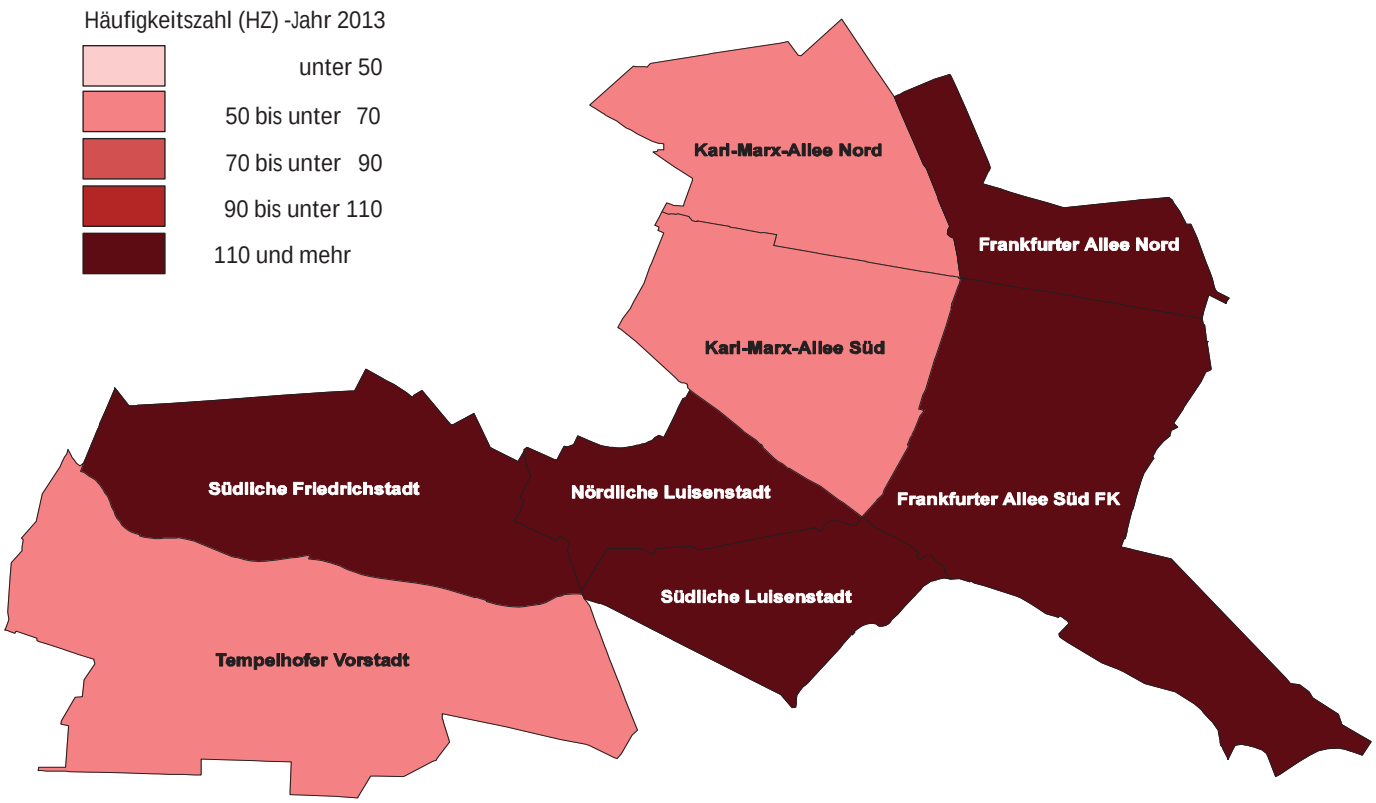

Branddelikte -insgesamt- (PKS-Schlüssel 640000, 674**2)

Bezirksregion	Jahr 2012		Jahr 2013		Zu-/Abnahme			
	erfasste Fälle	HZ	erfasste Fälle	HZ	Fälle		HZ	
					absolut	in %	absolut	in %
Südliche Friedrichstadt.....	46	118	45	114	- 1	x	- 4	(- 3,4)
Tempelhofer Vorstadt.....	58	95	35	56	- 23	x	- 39	x
Nördliche Luisenstadt.....	31	139	27	120	- 4	x	- 19	(- 13,7)
Südliche Luisenstadt.....	27	103	32	121	5	x	18	(17,5)
Karl-Marx-Allee Nord.....	15	67	14	62	- 1	x	- 5	x
Karl-Marx-Allee Süd.....	22	96	15	64	- 7	x	- 32	x
Frankfurter Allee Nord.....	48	177	33	120	- 15	x	- 57	(- 32,2)
Frankfurter Allee Süd FK.....	67	145	61	129	- 6	x	- 16	(- 11,0)
nicht zuzuordnen.....			3					

Bezirk Berlin Pankow

Branddelikte -insgesamt (Häufigkeitszahl)

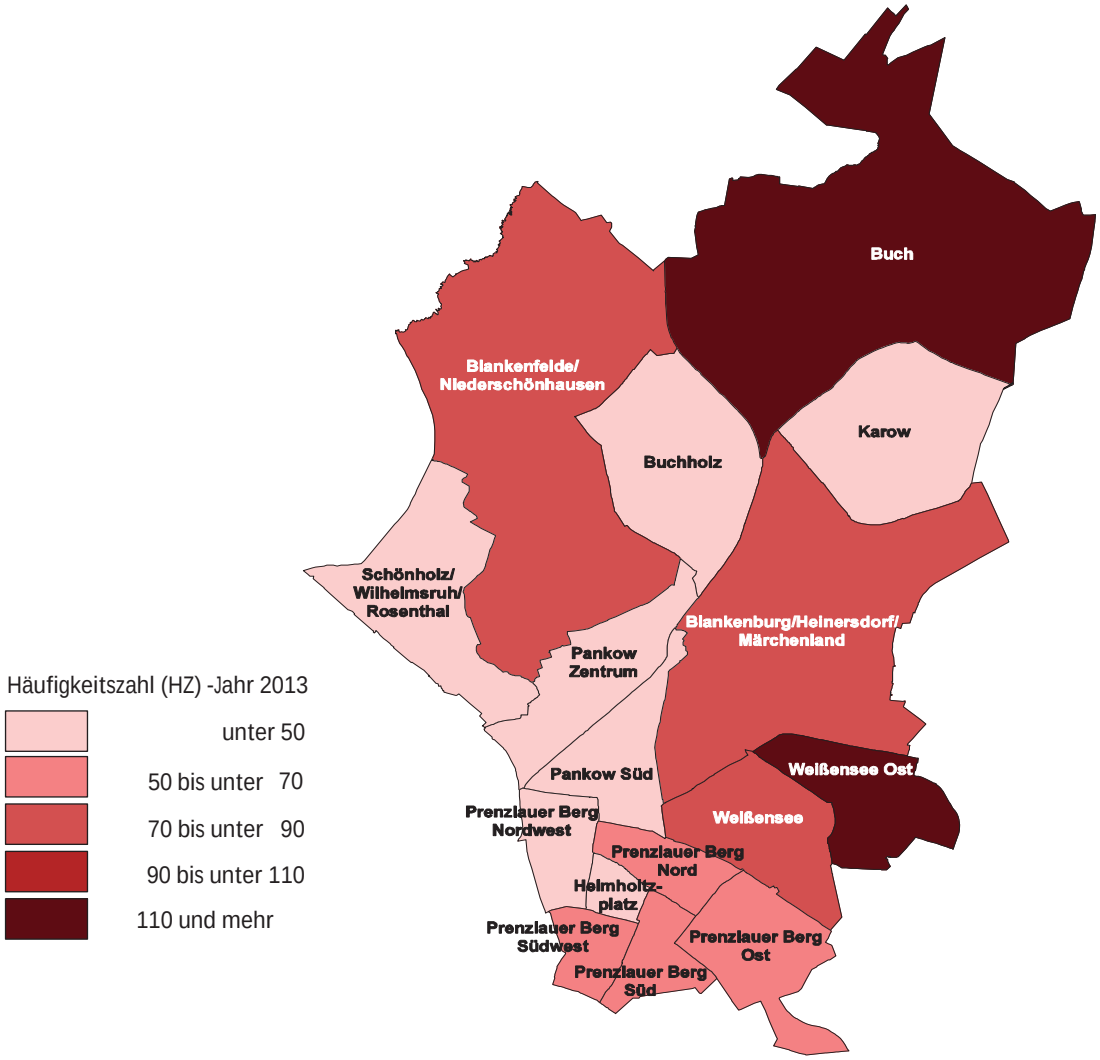

Branddelikte -insgesamt- (PKS-Schlüssel 640000, 674**2)

Bezirksregion	Jahr 2012		Jahr 2013		Zu-/Abnahme			
	erfasste Fälle	HZ	erfasste Fälle	HZ	Fälle		HZ	
					absolut	in %	absolut	in %
Buch	18	138	18	133		x	- 5	(- 3,6)
Blankenfelde/Niederschönhausen	26	103	21	81	- 5	x	- 22	(- 21,4)
Buchholz	10	60	2	12	- 8	x	- 48	x
Karow	10	53	6	32	- 4	x	- 21	x
Blankenburg/Heinersdorf	12	85	10	71	- 2	x	- 14	x
Pankow Süd	10	31	14	43	4	x	12	x
Schönholz/Wilhelmsruh/Rosenthal	7	41	6	35	- 1	x	- 6	x
Pankow Zentrum	13	40	14	42	1	x	2	x
Weißensee	18	55	25	74	7	x	19	x
Weißensee Ost	4	27	28	185	24	x	158	x
Prenzlauer Berg Nordwest	19	80	12	49	- 7	x	- 31	x
Prenzlauer Berg Nord	5	19	14	54	9	x	35	x
Helmholtzplatz	9	42	10	46	1	x	4	x
Prenzlauer Berg Ost	19	78	17	69	- 2	x	- 9	x
Prenzlauer Berg Südwest	10	41	16	64	6	x	23	x
Prenzlauer Berg Süd	15	49	17	55	2	x	6	x
nicht zuzuordnen	2		3					

Bezirk Berlin Charlottenburg-Wilmersdorf

Branddelikte -insgesamt (Häufigkeitszahl)

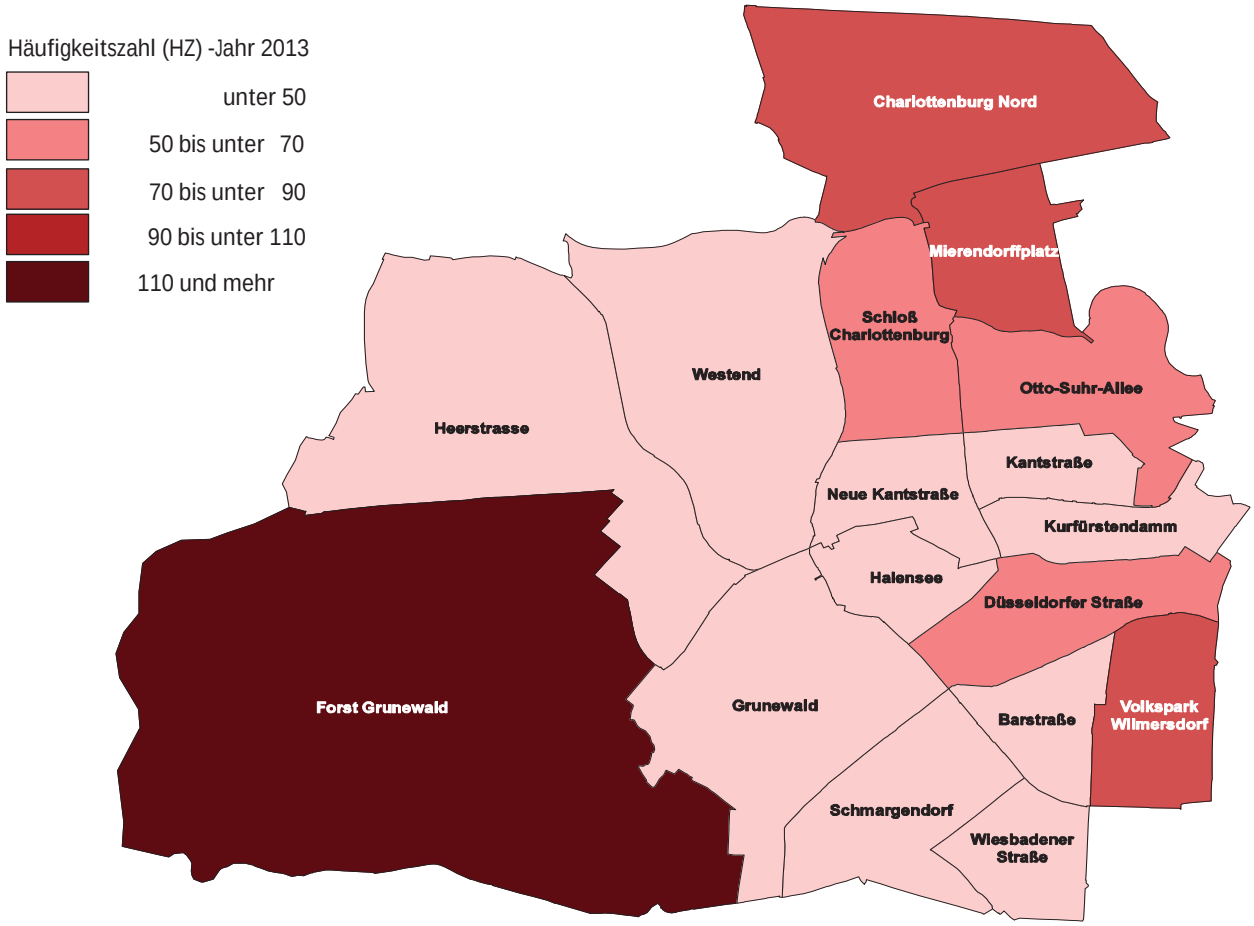

Branddelikte -insgesamt- (PKS-Schlüssel 640000, 674**2)

Bezirksregion	Jahr 2012		Jahr 2013		Zu-/Abnahme			
	erfasste Fälle	HZ	erfasste Fälle	HZ	Fälle absolut	Fälle in %	HZ absolut	HZ in %
Charlottenburg Nord.....	9	50	15	81	6	x	31	x
Heerstraße.....	7	56	3	24	- 4	x	- 32	x
Westend.....	7	27	10	38	3	x	11	x
Schloß Charlottenburg.....	9	39	12	51	3	x	12	x
Mierendorffplatz.....	12	84	11	75	- 1	x	- 9	x
Otto-Suhr-Allee.....	15	59	14	54	- 1	x	- 5	x
Neue Kantstraße.....	8	35	8	35		x		x
Kantstraße.....	9	44	8	39	- 1	x	- 5	x
Kurfürstendamm.....	7	48	6	41	- 1	x	- 7	x
Halensee.....	8	56	7	49	- 1	x	- 7	x
Grunewald.....	4	22	6	33	2	x	11	x
Schmargendorf.....	3	22	4	29	1	x	7	x
Wiesbadener Straße.....	1	6	2	11	1	x	5	x
Düsseldorfer Straße.....	14	48	15	50	1	x	2	x
Barstraße.....	6	44	1	7	- 5	x	- 37	x
Volkspark Wilmersdorf.....	10	31	24	73	14	x	42	x
Forst Grunewald.....	2		2			x		
nicht zuzuordnen.....	2		1					

Bezirk Berlin Spandau

Branddelikte -insgesamt (Häufigkeitszahl)

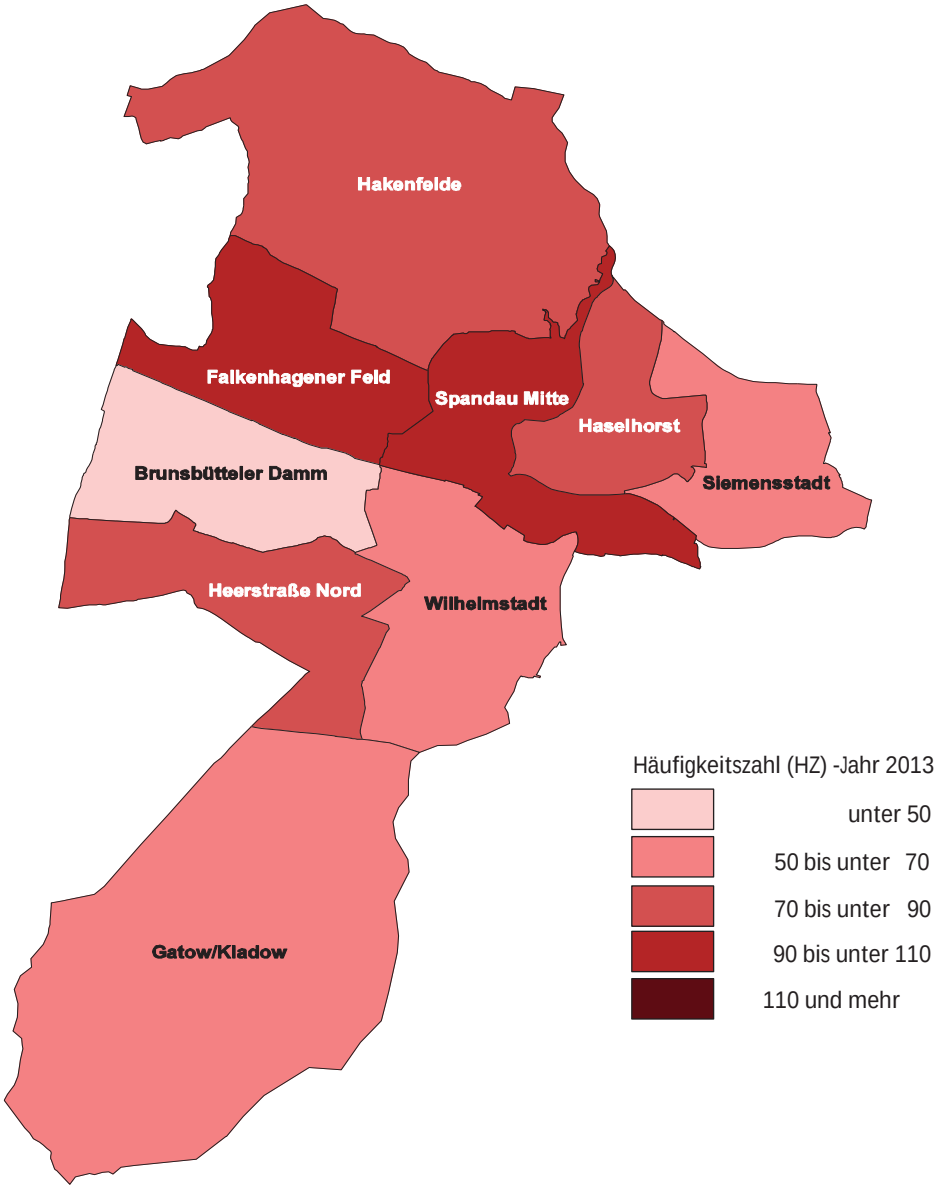

Branddelikte -insgesamt- (PKS-Schlüssel 640000, 674**2)

Bezirksregion	Jahr 2012		Jahr 2013		Zu-/Abnahme			
	erfasste Fälle	HZ	erfasste Fälle	HZ	Fälle absolut	Fälle in %	HZ absolut	HZ in %
Hakenfelde.....	6	26	20	88	14	x	62	x
Falkenhagener Feld.....	28	72	40	102	12	x	30	x
Spandau Mitte.....	26	79	31	92	5	x	13	x
Brunsbütteler Damm.....	22	95	10	43	- 12	x	- 52	x
Heerstraße Nord.....	33	124	19	71	- 14	x	- 53	(- 42,7)
Wilhelmstadt.....	25	74	21	61	- 4	x	- 13	x
Haselhorst.....	10	73	11	76	1	x	3	x
Siemensstadt.....	8	69	8	67		x	- 2	x
Gatow/Kladow.....	13	73	11	61	- 2	x	- 12	x
nicht zuzuordnen.....	4		3					

Bezirk Berlin Steglitz-Zehlendorf

Branddelikte -insgesamt (Häufigkeitszahl)

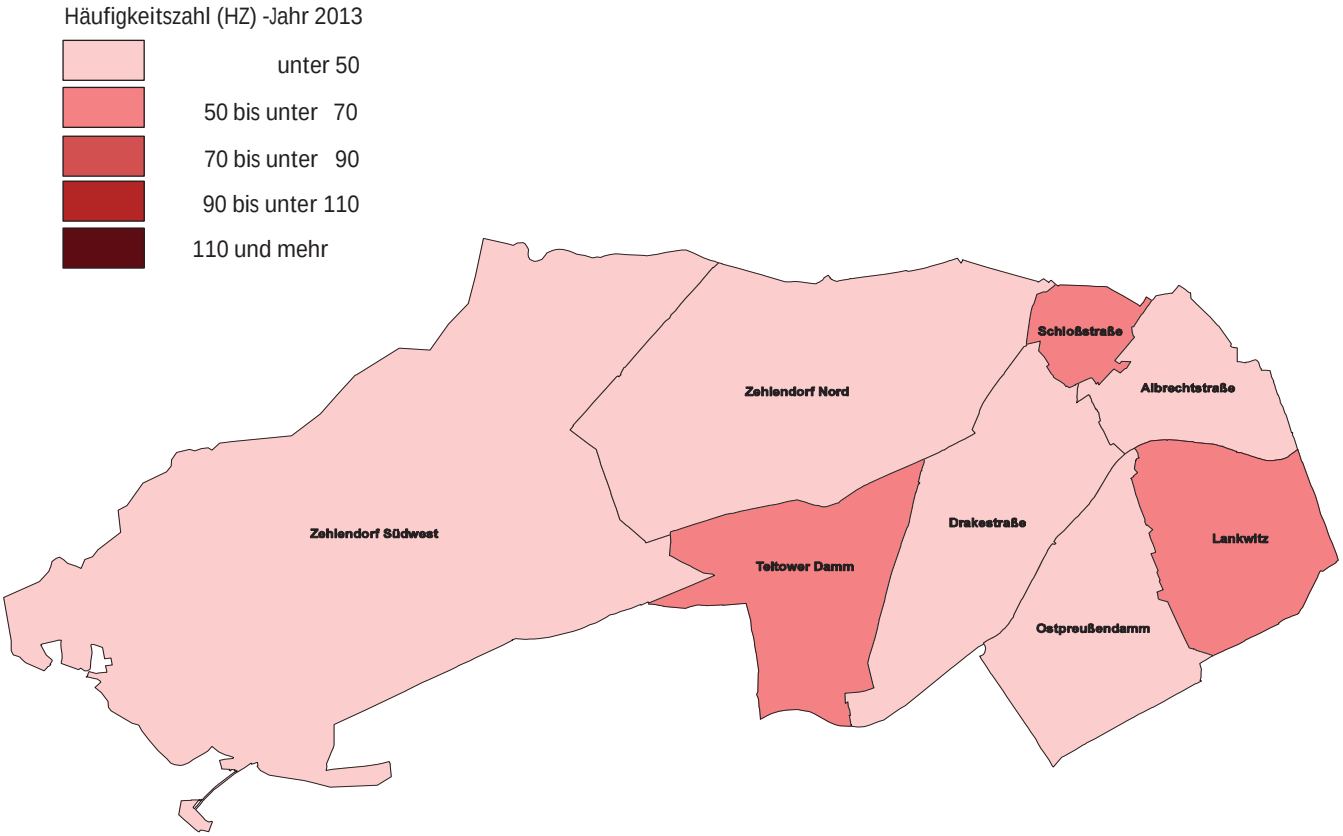

Branddelikte -insgesamt- (PKS-Schlüssel 640000, 674**2)

Bezirksregion	Jahr 2012		Jahr 2013		Zu-/Abnahme			
	erfasste Fälle	HZ	erfasste Fälle	HZ	Fälle		HZ	
					absolut	in %	absolut	in %
Schloßstraße.....	11	51	12	56	1	x	5	x
Albrechtstraße.....	14	27	17	33	3	x	6	x
Lankwitz.....	11	27	24	57	13	x	30	x
Ostpreußendamm.....	13	38	12	34	- 1	x	- 4	x
Teltower Damm.....	10	31	17	52	7	x	21	x
Drakestraße.....	15	33	17	37	2	x	4	x
Zehlendorf Südwest.....	21	82	9	35	- 12	x	- 47	x
Zehlendorf Nord.....	20	48	17	41	- 3	x	- 7	x
nicht zuzuordnen.....			2					

Bezirk Berlin Tempelhof-Schöneberg

Branddelikte -insgesamt (Häufigkeitszahl)

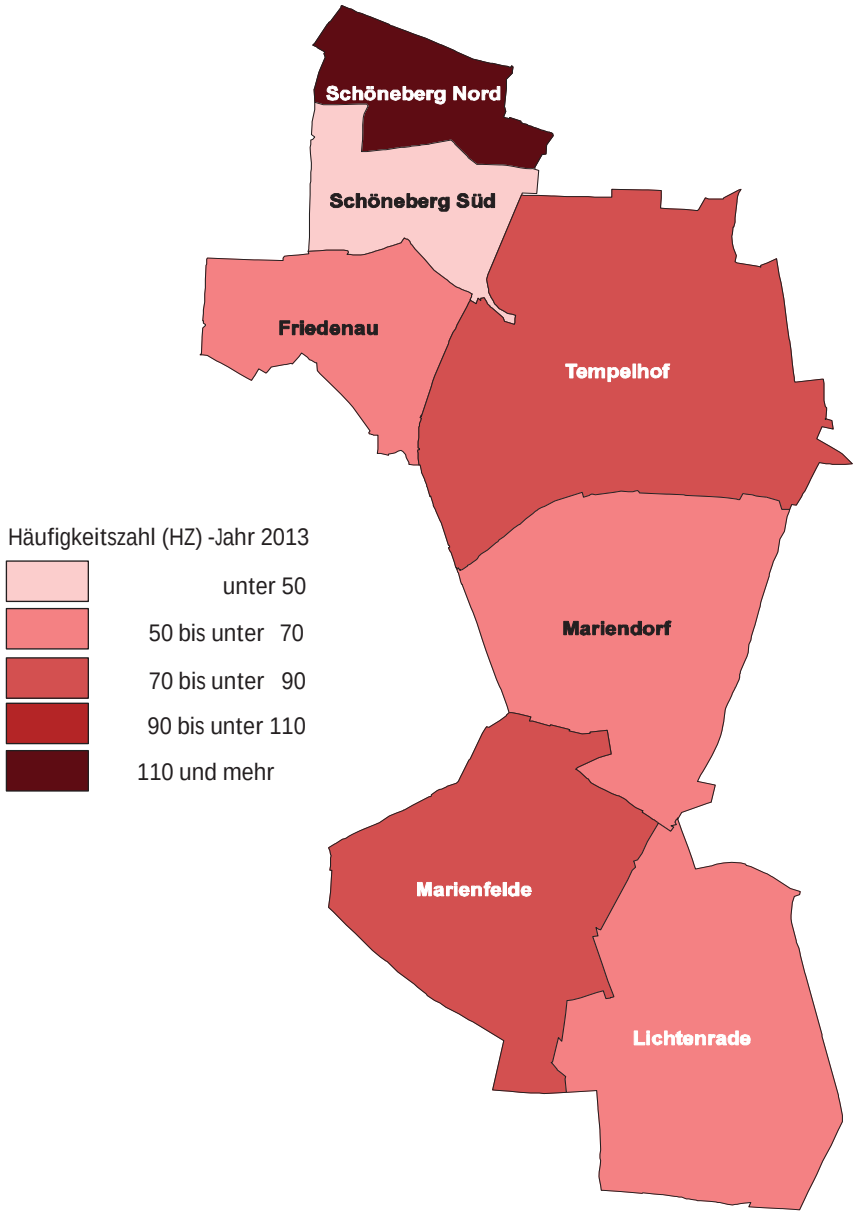

Branddelikte -insgesamt- (PKS-Schlüssel 640000, 674**2)

Bezirksregion	Jahr 2012		Jahr 2013		Zu-/Abnahme			
	erfasste Fälle	HZ	erfasste Fälle	HZ	Fälle		HZ	
					absolut	in %	absolut	in %
Schöneberg Nord.....	31	66	54	115	23	x	49	x
Schöneberg Süd.....	26	55	23	48	- 3	x	- 7	x
Friedenau.....	22	50	28	63	6	x	13	x
Tempelhof.....	50	85	48	80	- 2	x	- 5	x
Mariendorf.....	29	58	27	54	- 2	x	- 4	x
Marienfelde.....	18	59	22	72	4	x	13	x
Lichtenrade.....	32	65	29	58	- 3	x	- 7	x
nicht zuzuordnen.....			1					

Bezirk Berlin Neukölln

Branddelikte -insgesamt (Häufigkeitszahl)

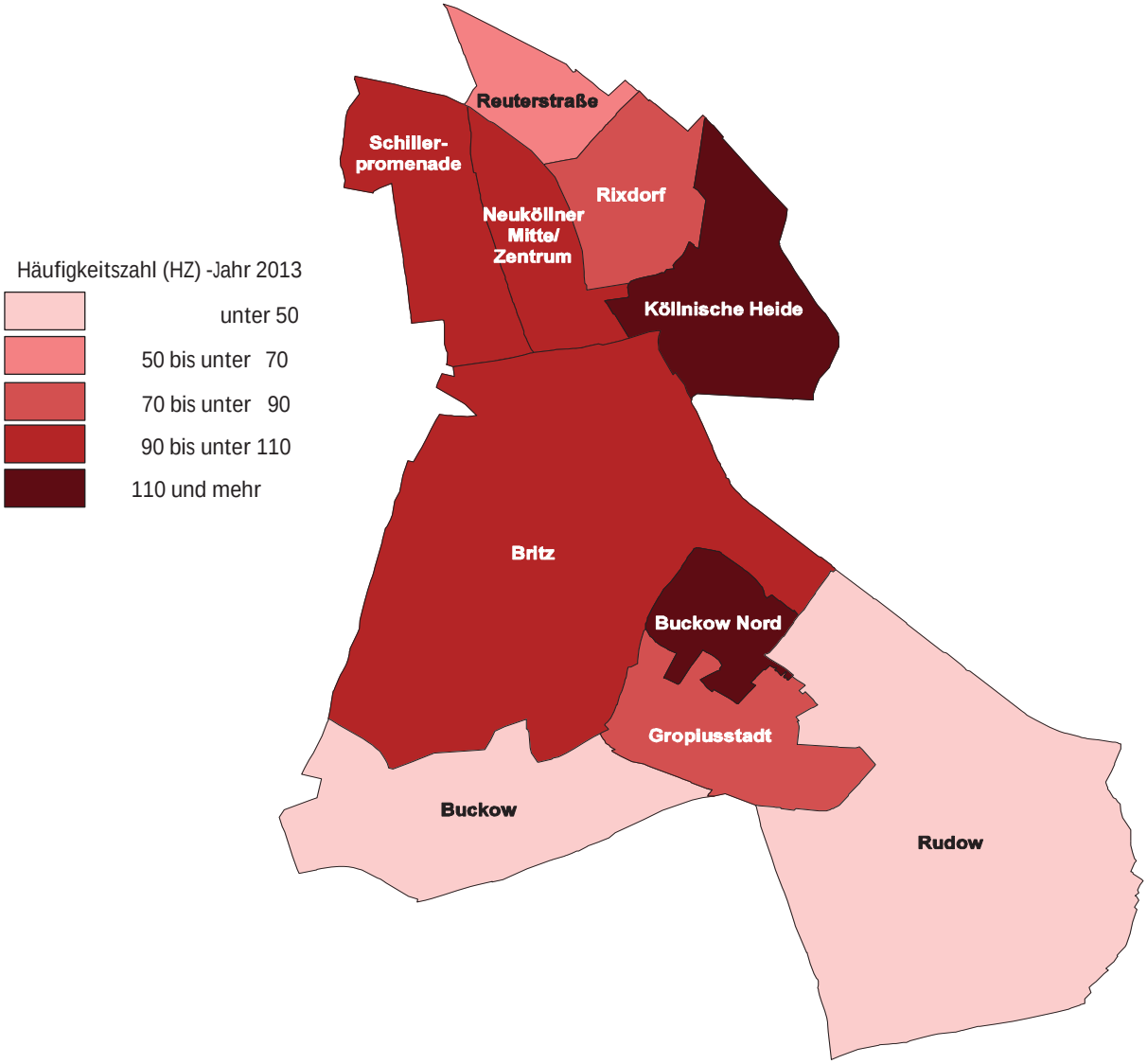

Branddelikte -insgesamt- (PKS-Schlüssel 640000, 674**2)

Bezirksregion	Jahr 2012		Jahr 2013		Zu-/Abnahme			
	erfasste Fälle	HZ	erfasste Fälle	HZ	Fälle absolut	Fälle in %	HZ absolut	HZ in %
Schillerpromenade.....	31	100	32	101	1	x	1	(1,0)
Neuköllner Mitte/Zentrum.....	67	182	39	103	- 28	x	- 79	(- 43,4)
Reuterstraße.....	24	62	27	68	3	x	6	x
Rixdorf.....	32	82	31	78	- 1	x	- 4	x
Köllnische Heide.....	15	102	21	140	6	x	38	(37,3)
Britz.....	27	67	39	95	12	x	28	x
Buckow.....	11	40	11	39		x	- 1	x
Gropiusstadt.....	13	36	28	77	15	x	41	x
Buckow Nord.....	6	65	13	139	7	x	74	x
Rudow.....	15	36	10	24	- 5	x	- 12	x
nicht zuzuordnen.....	1							

Bezirk Berlin Treptow-Köpenick

Branddelikte -insgesamt (Häufigkeitszahl)

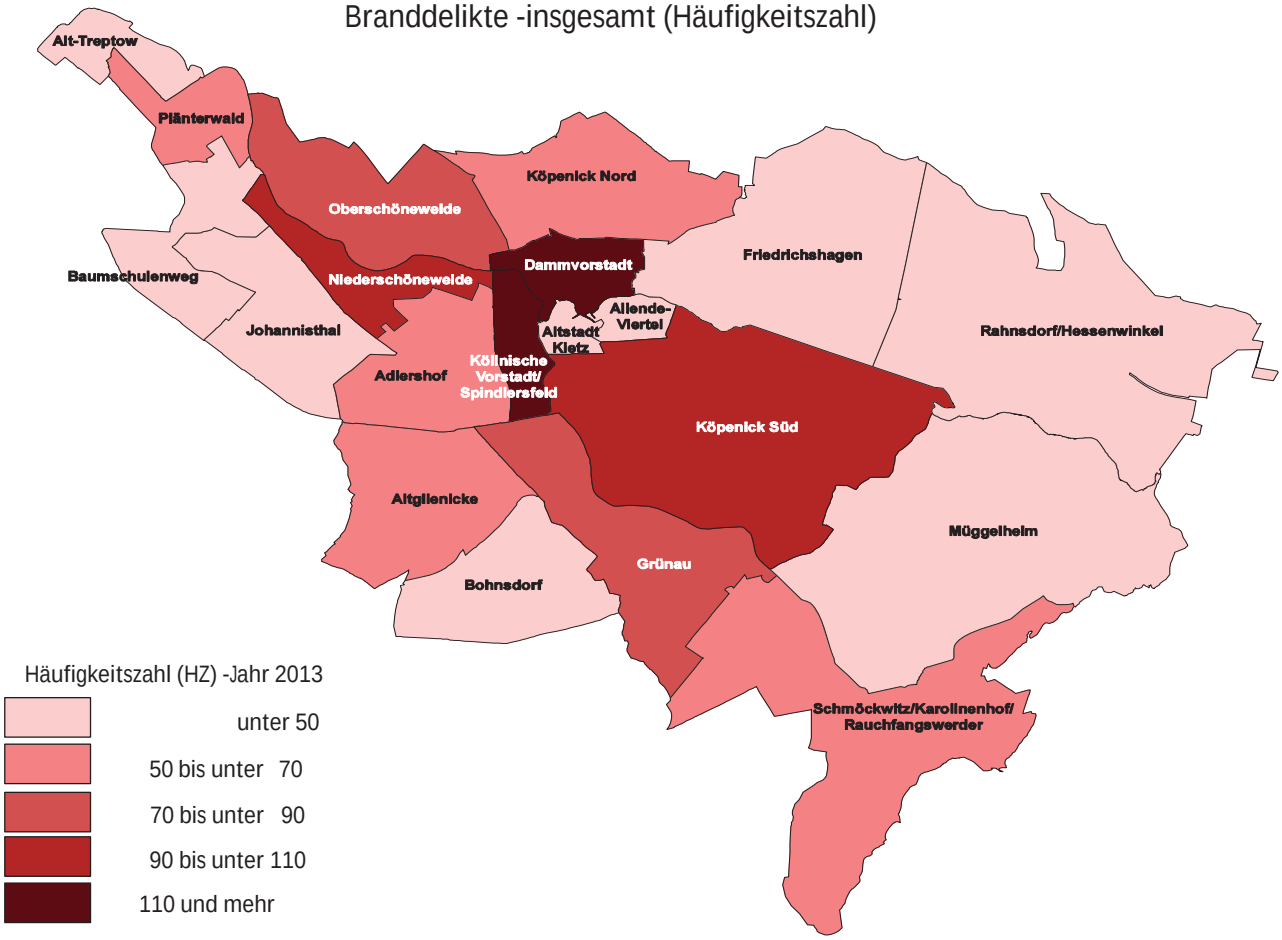

Branddelikte -insgesamt- (PKS-Schlüssel 640000, 674**2)

Bezirksregion	Jahr 2012		Jahr 2013		Zu-/Abnahme			
	erfasste Fälle	HZ	erfasste Fälle	HZ	Fälle absolut	Fälle in %	HZ absolut	HZ in %
Alt-Treptow	3	27	2	18	- 1	x	- 9	x
Plänterwald	6	56	7	65	1	x	9	x
Baumschulenweg	10	58	8	46	- 2	x	- 12	x
Johannisthal	8	44	9	49	1	x	5	x
Oberschöneweide	20	104	14	71	- 6	x	- 33	(- 31,7)
Niederschöneweide	11	105	11	103		x	- 2	(- 1,9)
Adlershof	8	52	10	64	2	x	12	x
Kölln. Vorstadt/Spindlersf.	15	152	20	200	5	x	48	(31,6)
Altglienicke	9	35	15	58	6	x	23	x
Bohnsdorf	8	67	5	41	- 3	x	- 26	x
Grünau	2	37	4	71	2	x	34	x
Schmöckwitz/Karolinenhof	3	74	2	50	- 1	x	- 24	x
Köpenick Süd	8	51	16	103	8	x	52	x
Allende-Viertel	1	16	3	49	2	x	33	x
Altstadt Kietz	5	73	3	43	- 2	x	- 30	x
Müggelheim	1	15	2	31	1	x	16	x
Friedrichshagen	5	29	8	46	3	x	17	x
Rahnsdorf/Hessenwinkel	2	22	2	22		x		x
Dammvorstadt	13	138	20	210	7	x	72	(52,2)
Köpenick Nord	3	24	8	65	5	x	41	x
nicht zuzuordnen	3		2					

Bezirk Berlin Marzahn-Hellersdorf

Branddelikte -insgesamt (Häufigkeitszahl)

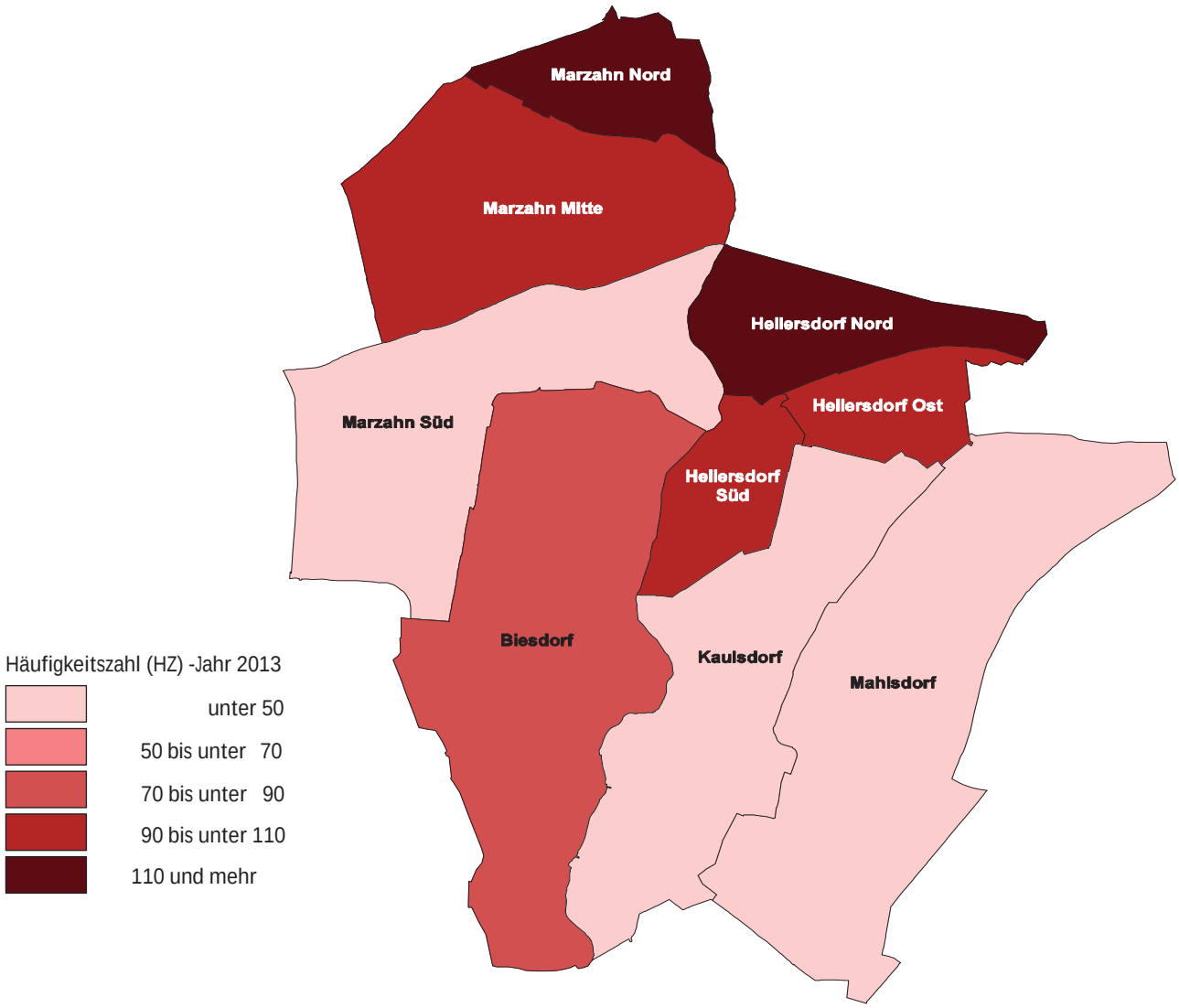

Branddelikte -insgesamt- (PKS-Schlüssel 640000, 674**2)

Bezirksregion	Jahr 2012		Jahr 2013		Zu-/Abnahme			
	erfasste Fälle	HZ	erfasste Fälle	HZ	Fälle absolut	Fälle in %	HZ absolut	HZ in %
Marzahn Nord	33	146	32	140	- 1	x	- 6	(- 4,1)
Marzahn Mitte	49	108	47	103	- 2	x	- 5	(- 4,6)
Marzahn Süd	37	102	17	46	- 20	x	- 56	(- 54,9)
Hellersdorf Nord	57	174	72	216	15	x	42	(24,1)
Hellersdorf Ost	30	163	19	101	- 11	x	- 62	(- 38,0)
Hellersdorf Süd	20	82	26	106	6	x	24	x
Biesdorf	9	36	18	71	9	x	35	x
Kaulsdorf	2	11	6	32	4	x	21	x
Mahlsdorf	4	15	2	7	- 2	x	- 8	x
nicht zuzuordnen	1		1					

Bezirk Berlin Lichtenberg

Branddelikte -insgesamt (Häufigkeitszahl)

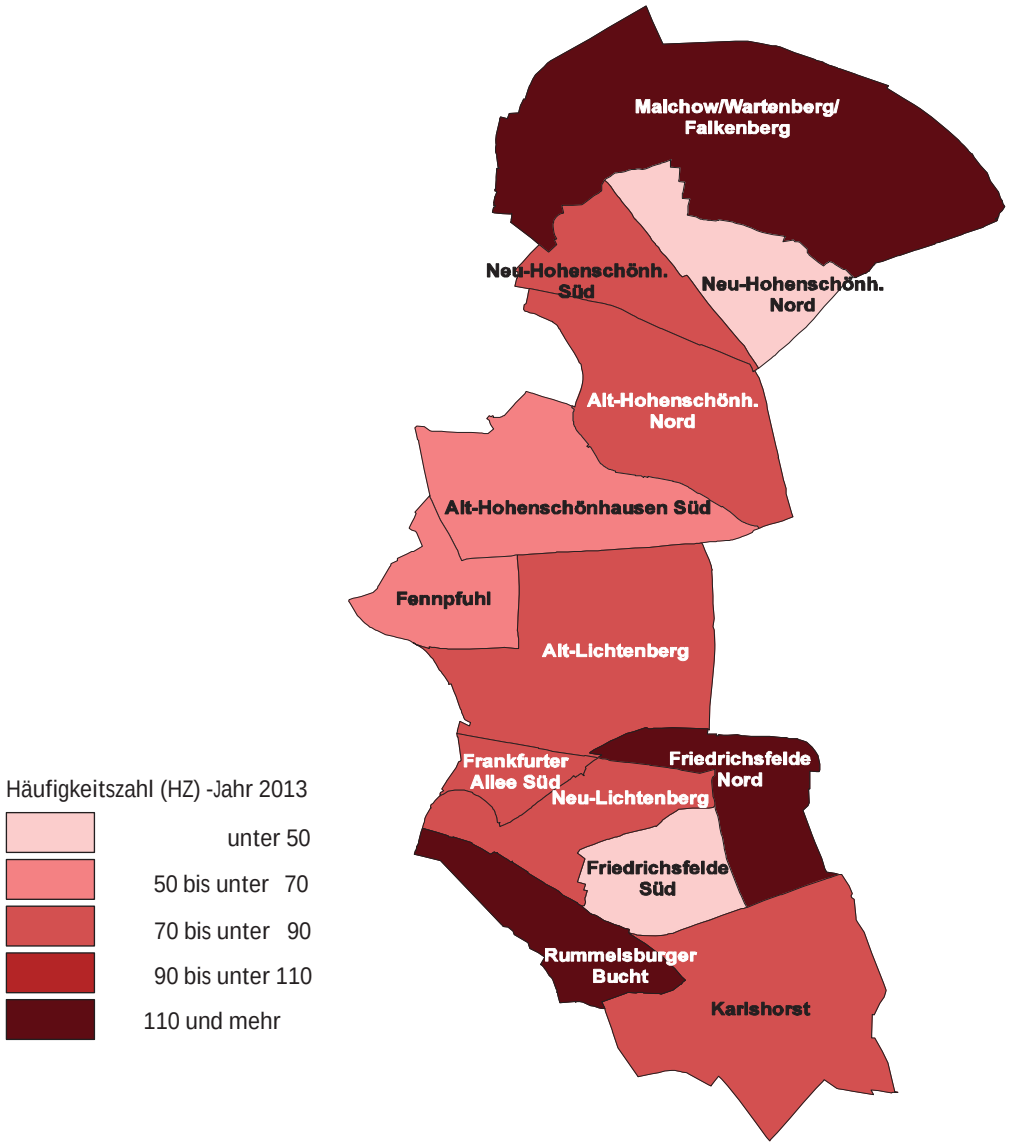

Branddelikte -insgesamt- (PKS-Schlüssel 640000, 674**2)

Bezirksregion	Jahr 2012		Jahr 2013		Zu-/Abnahme			
	erfasste Fälle	HZ	erfasste Fälle	HZ	Fälle absolut	Fälle in %	HZ absolut	HZ in %
Malchow/Warten-/Falkenberg.....	11	262	5	118	- 6	x	- 144	(- 55,0)
Neu-Hohenschönhausen Nord.....	15	55	13	47	- 2	x	- 8	x
Neu-Hohenschönhausen Süd.....	20	77	21	81	1	x	4	x
Alt-Hohenschönhausen Nord.....	7	52	11	82	4	x	30	x
Alt-Hohenschönhausen Süd.....	12	41	15	51	3	x	10	x
Fennpfuhl.....	17	54	17	53		x	- 1	x
Alt-Lichtenberg.....	26	108	22	88	- 4	x	- 20	(- 18,5)
Frankfurter Allee Süd.....	6	62	8	80	2	x	18	x
Neu-Lichtenberg.....	30	102	24	80	- 6	x	- 22	(- 21,6)
Friedrichsfelde Nord.....	7	53	20	148	13	x	95	x
Friedrichsfelde Süd.....	10	41	11	45	1	x	4	x
Rummelsburger Bucht.....	16	490	22	664	6	x	174	(35,5)
Karlshorst.....	8	35	19	82	11	x	47	x
nicht zuzuordnen.....	2		1					

Bezirk Berlin Reinickendorf

Branddelikte -insgesamt (Häufigkeitszahl)

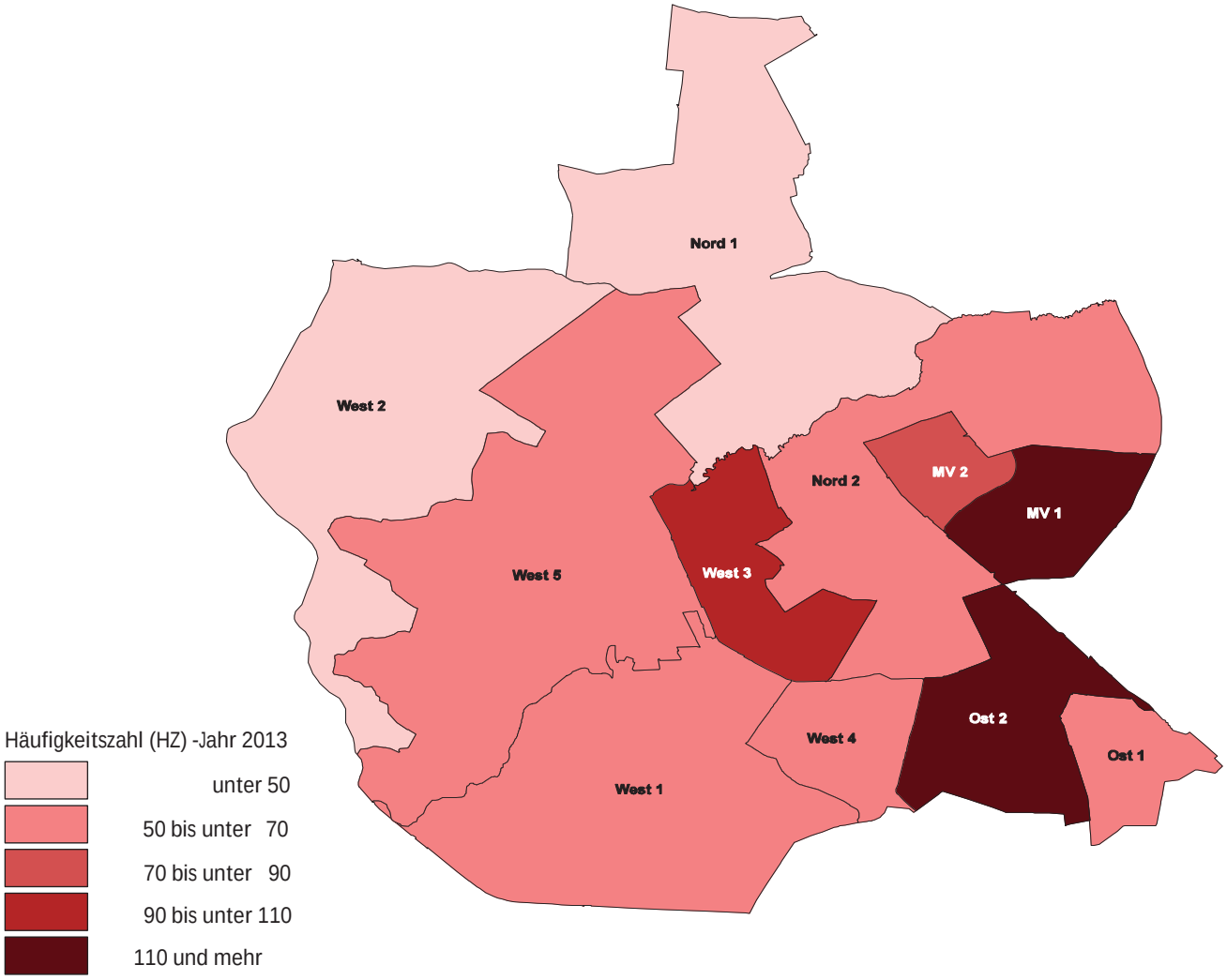

Branddelikte -insgesamt- (PKS-Schlüssel 640000, 674**2)

Bezirksregion	Jahr 2012		Jahr 2013		Zu-/Abnahme			
	erfasste Fälle	HZ	erfasste Fälle	HZ	Fälle		HZ	
					absolut	in %	absolut	in %
Ost 1.....	11	43	16	62	5	x	19	x
Ost 2.....	22	86	30	116	8	x	30	x
West 1.....	12	82	10	69	- 2	x	- 13	x
West 4.....	15	60	14	55	- 1	x	- 5	x
West 5.....	7	69	6	58	- 1	x	- 11	x
West 2.....	11	47	10	42	- 1	x	- 5	x
Nord 1.....	7	21	7	21		x		x
Nord 2.....	16	55	16	54		x	- 1	x
MV 1.....	74	209	44	121	- 30	x	- 88	(- 42,1)
MV 2.....	7	85	6	71	- 1	x	- 14	x
West 3.....	5	31	17	106	12	x	75	x
nicht zuzuordnen.....	6		6					

Berlin - Brandstiftung (Häufigkeitszahl)

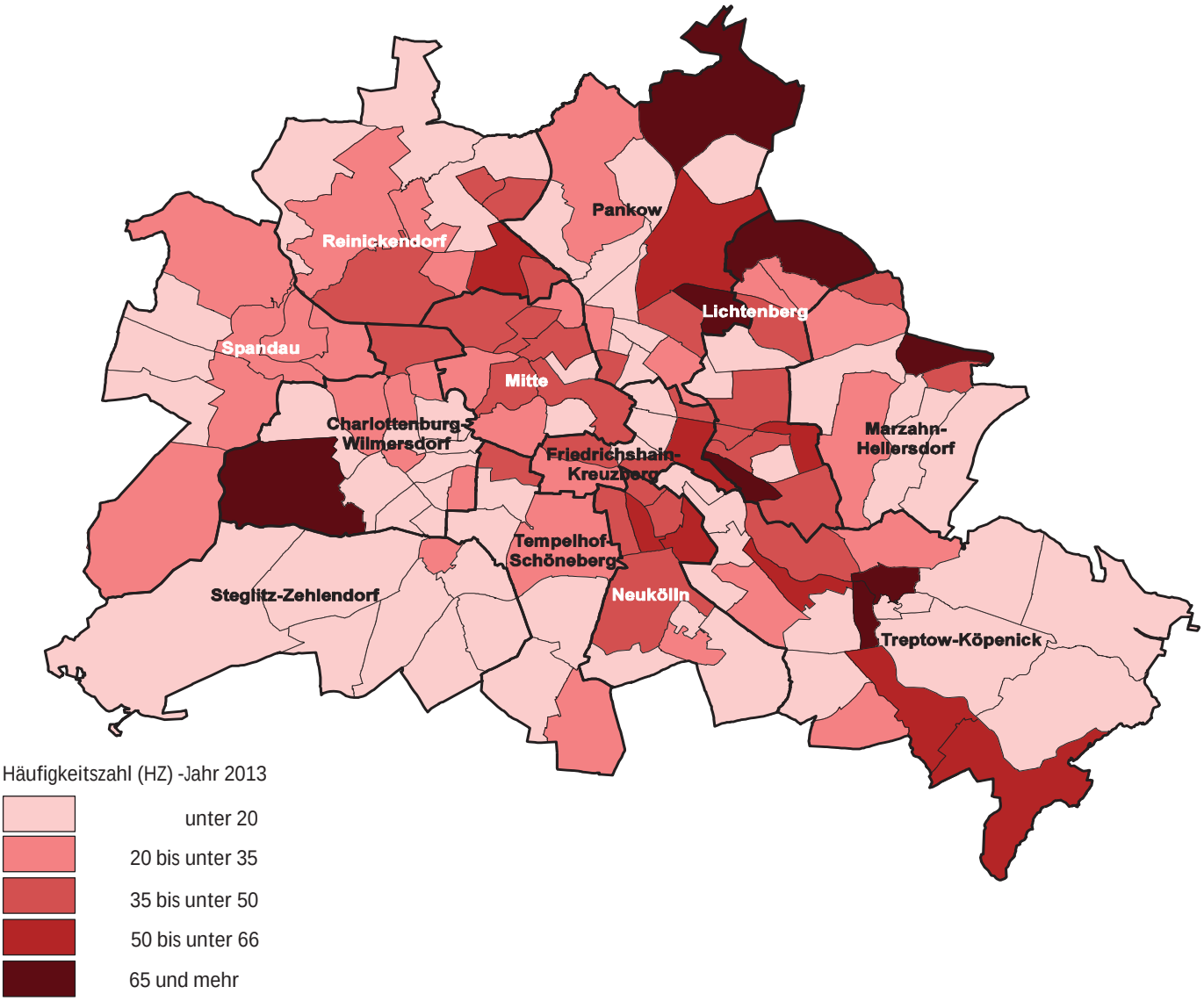

Brandstiftung (PKS-Schlüssel 640000)

Bezirk	Jahr 2012		Jahr 2013		Zu-/Abnahme			
	erfasste Fälle	HZ	erfasste Fälle	HZ	Fälle absolut	Fälle in %	HZ absolut	HZ in %
Mitte	140	42	121	35	- 19	- 13,6	- 7	- 16,7
Friedrichshain-Kreuzberg	105	39	90	33	- 15	- 14,3	- 6	- 15,4
Pankow	83	23	111	30	28	33,7	7	30,4
Charlottenburg-Wilmersdorf	45	14	64	20	19	42,2	6	42,9
Spandau	61	28	45	20	- 16	- 26,2	- 8	- 28,6
Steglitz-Zehlendorf	39	13	40	13	1	2,6	-	-
Tempelhof-Schöneberg	69	21	67	20	- 2	- 2,9	- 1	- 4,8
Neukölln	95	30	102	32	7	7,4	2	6,7
Treptow-Köpenick	60	25	76	31	16	26,7	6	24,0
Marzahn-Hellersdorf	77	31	82	32	5	6,5	1	3,2
Lichtenberg	67	26	91	35	24	35,8	9	34,6
Reinickendorf	63	26	83	33	20	31,7	7	26,9
Berlin, nicht zuzuordnen	5		1					
Berlin -Gesamt-	**909**	**27**	**973**	**29**	**64**	**7,0**	**2**	**6,0**

Bezirk Berlin Mitte

Brandstiftung (Häufigkeitszahl)

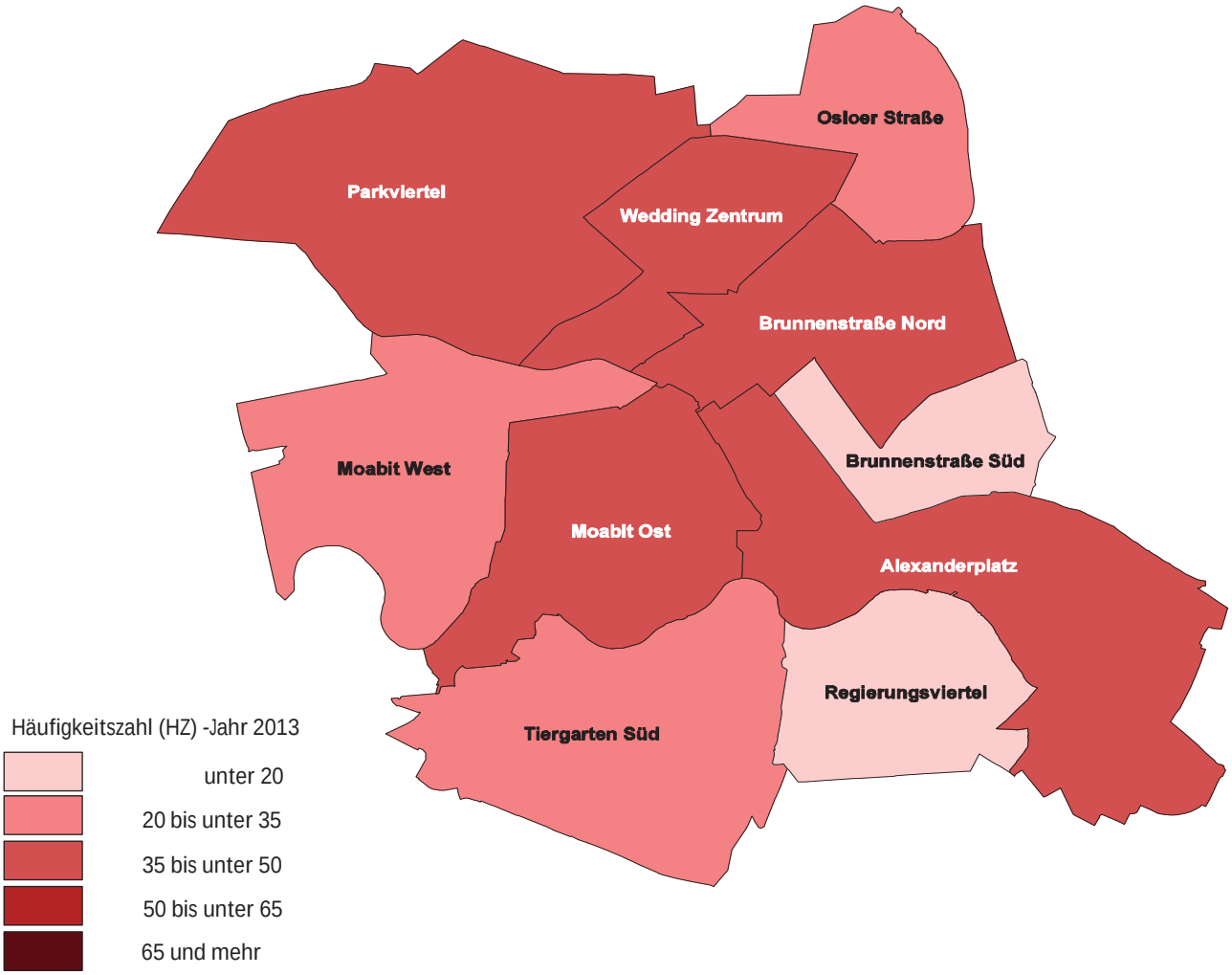

Brandstiftung (PKS-Schlüssel 640000)

Bezirksregion	Jahr 2012		Jahr 2013		Zu-/Abnahme			
	erfasste Fälle	HZ	erfasste Fälle	HZ	Fälle		HZ	
					absolut	in %	absolut	in %
Tiergarten Süd.....	4	32	3	23	- 1	x	- 9	x
Regierungsviertel.....	4	44	1	11	- 3	x	- 33	x
Alexanderplatz.....	27	57	20	42	- 7	x	- 15	x
Brunnenstraße Süd.....	5	20	3	11	- 2	x	- 9	x
Moabit West.....	22	53	12	28	- 10	x	- 25	x
Moabit Ost.....	10	29	16	45	6	x	16	x
Osloer Straße.....	18	51	8	22	- 10	x	- 29	x
Brunnenstraße Nord.....	7	20	13	36	6	x	16	x
Parkviertel.....	20	48	16	38	- 4	x	- 10	x
Wedding Zentrum.....	23	44	25	46	2	x	2	x
nicht zuzuordnen.....		-	4	-				

Bezirk Berlin Friedrichshain-Kreuzberg

Brandstiftung (Häufigkeitszahl)

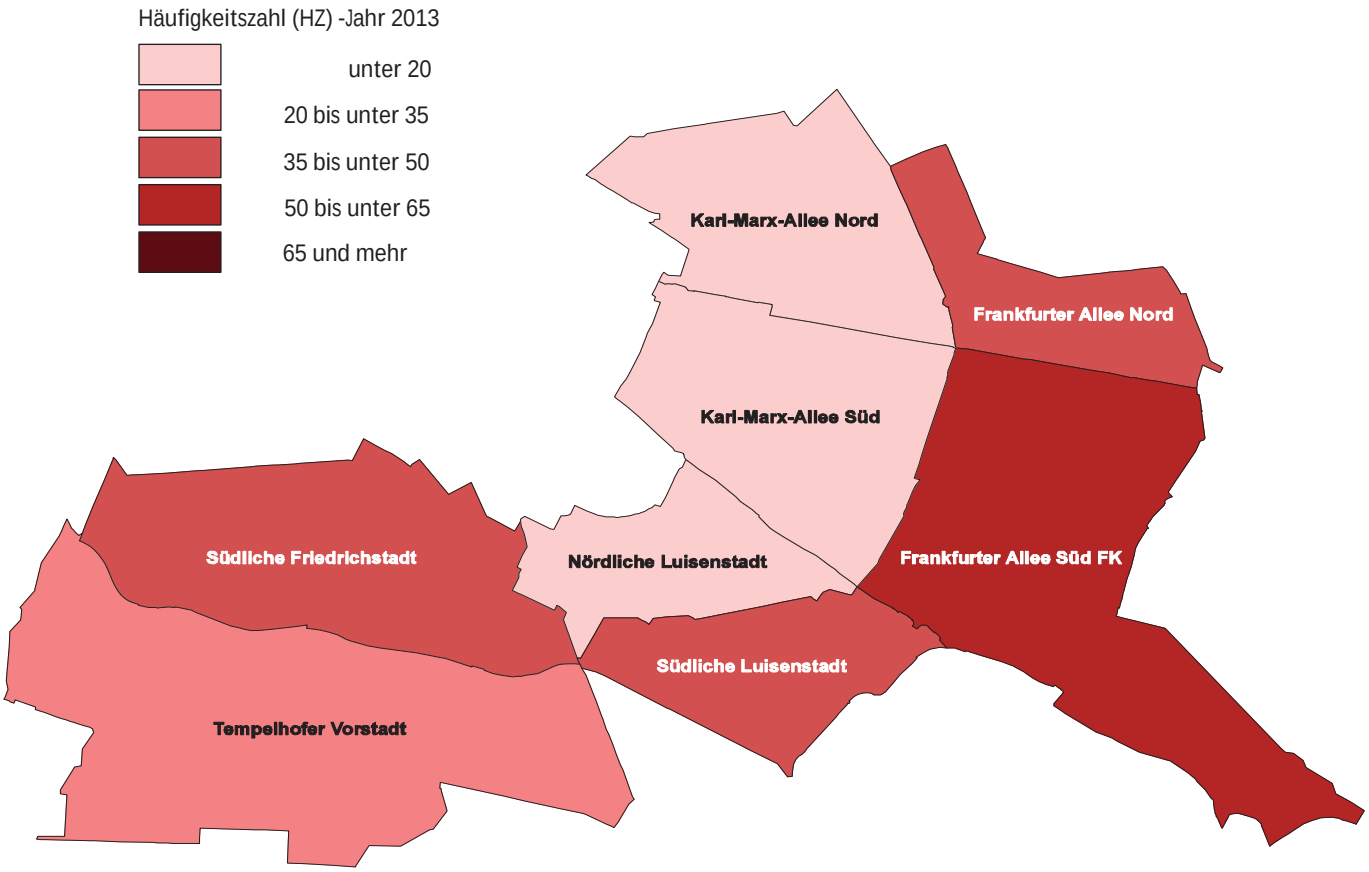

Brandstiftung (PKS-Schlüssel 640000)

Bezirksregion	Jahr 2012		Jahr 2013		Zu-/Abnahme			
	erfasste Fälle	HZ	erfasste Fälle	HZ	Fälle		HZ	
					absolut	in %	absolut	in %
Südliche Friedrichstadt.....	13	33	15	38	2	x	5	x
Tempelhofer Vorstadt.....	21	34	14	23	- 7	x	- 11	x
Nördliche Luisenstadt.....	10	45	4	18	- 6	x	- 27	x
Südliche Luisenstadt.....	11	42	13	49	2	x	7	x
Karl-Marx-Allee Nord.....	5	22	2	9	- 3	x	- 13	x
Karl-Marx-Allee Süd.....	7	31	3	13	- 4	x	- 18	x
Frankfurter Allee Nord.....	15	55	13	47	- 2	x	- 8	x
Frankfurter Allee Süd FK.....	22	48	26	55	4	x	7	x
nicht zuzuordnen.....	1							

Bezirk Berlin Pankow

Brandstiftung (Häufigkeitszahl)

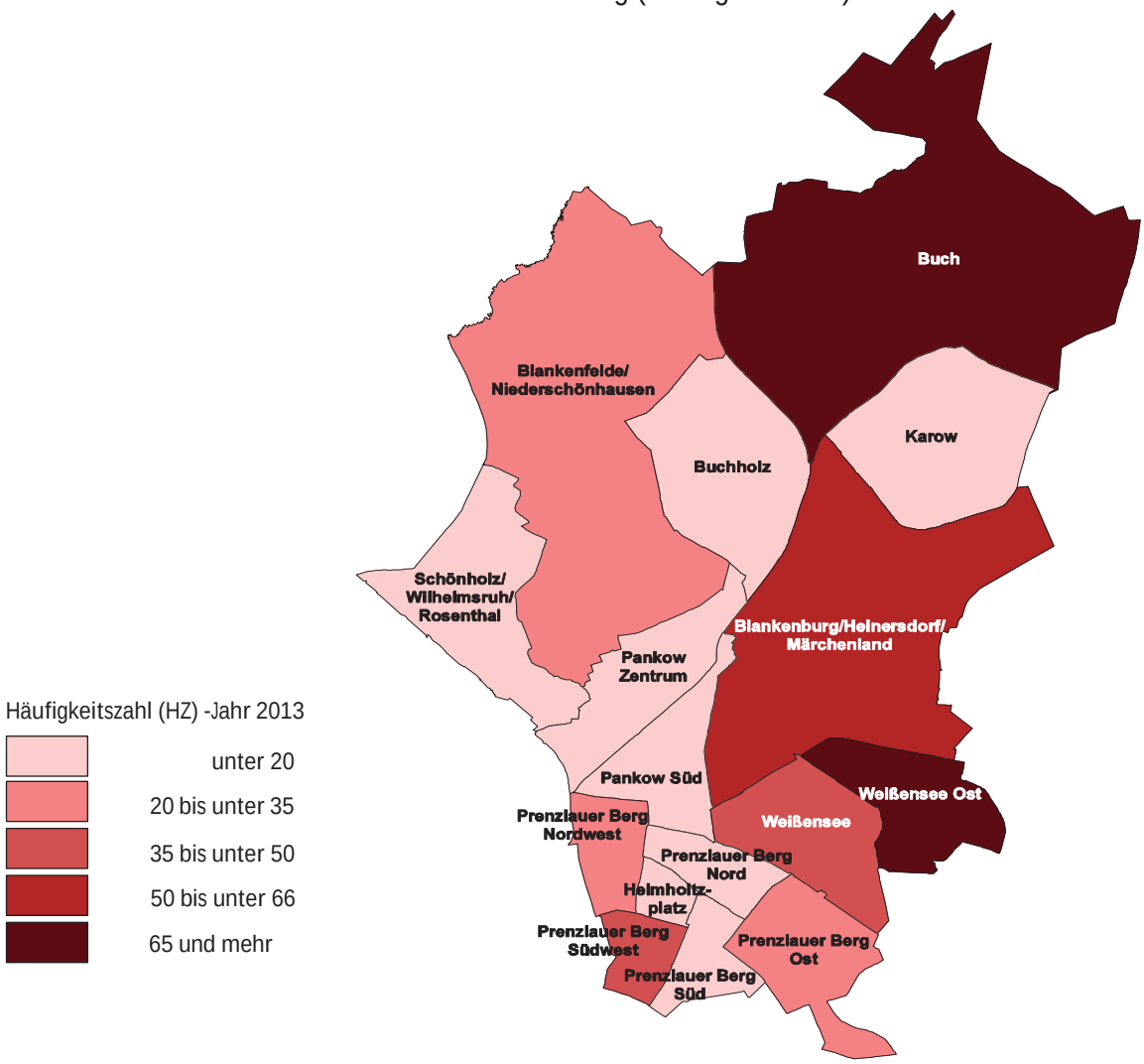

Brandstiftung (PKS-Schlüssel 640000)

Bezirksregion	Jahr 2012		Jahr 2013		Zu-/Abnahme			
	erfasste Fälle	HZ	erfasste Fälle	HZ	Fälle		HZ	
					absolut	in %	absolut	in %
Buch	6	46	9	66	3	x	20	x
Blankenfelde/Niederschönhausen	14	55	8	31	- 6	x	- 24	x
Buchholz	1	6		-	- 1	x	- 6	x
Karow	6	32	3	16	- 3	x	- 16	x
Blankenburg/Heinersdorf	4	28	7	50	3	x	22	x
Pankow Süd	7	22	5	15	- 2	x	- 7	x
Schönholz/Wilhelmsruh/Rosenthal	1	6	3	17	2	x	11	x
Pankow Zentrum	5	15	6	18	1	x	3	x
Weißensee	11	33	16	48	5	x	15	x
Weißensee Ost	1	7	22	145	21	x	138	x
Prenzlauer Berg Nordwest	8	34	6	25	- 2	x	- 9	x
Prenzlauer Berg Nord		-	3	11	3	x	11	x
Helmholtzplatz	3	14	2	9	- 1	x	- 5	x
Prenzlauer Berg Ost	9	37	5	20	- 4	x	- 17	x
Prenzlauer Berg Südwest	2	8	9	36	7	x	28	x
Prenzlauer Berg Süd	4	13	6	19	2	x	6	x
nicht zuzuordnen	1		1					

Bezirk Berlin Charlottenburg-Wilmersdorf

Brandstiftung (Häufigkeitszahl)

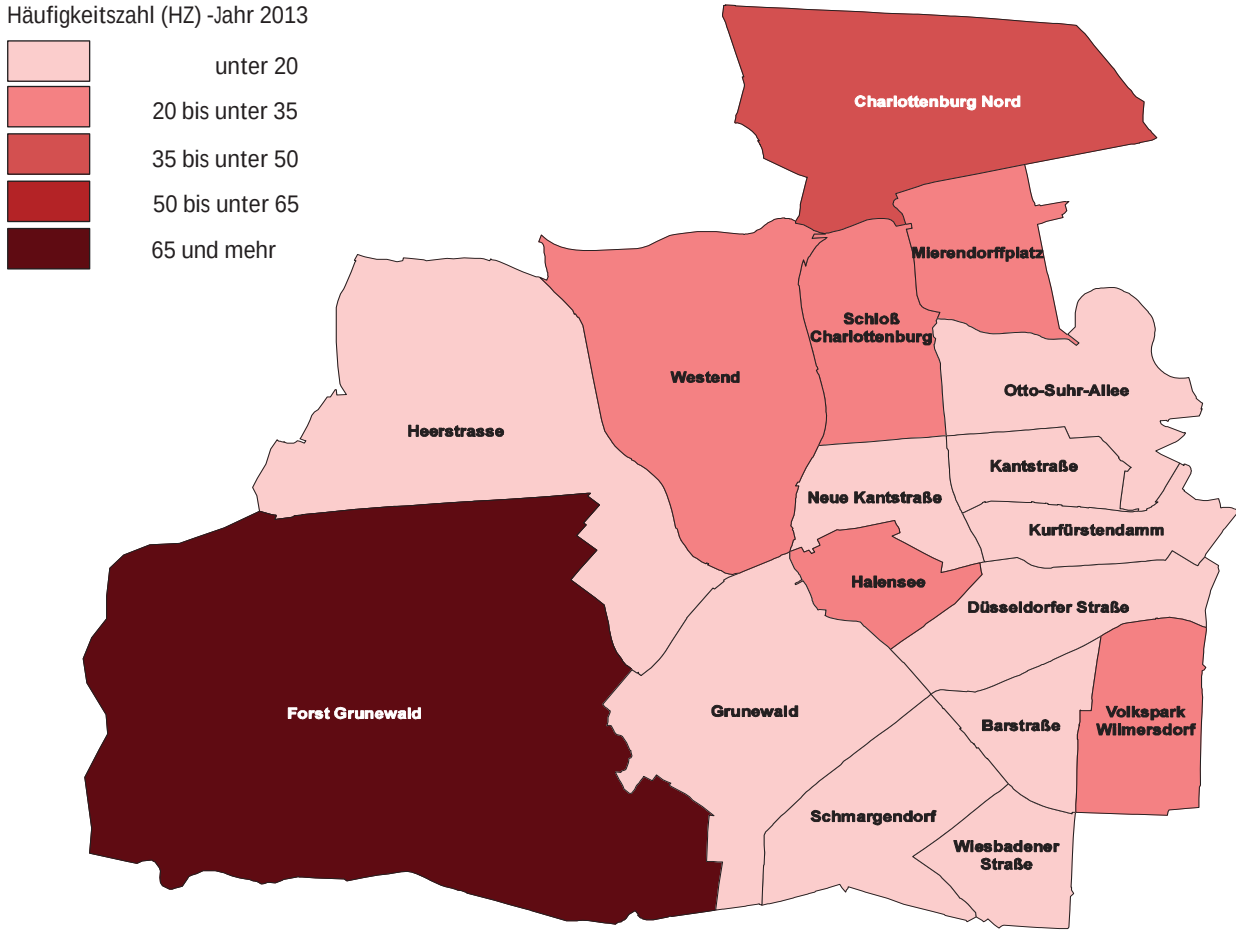

Brandstiftung (PKS-Schlüssel 640000)

Bezirksregion	Jahr 2012		Jahr 2013		Zu-/Abnahme			
	erfasste Fälle	HZ	erfasste Fälle	HZ	Fälle		HZ	
					absolut	in %	absolut	in %
Charlottenburg Nord.....	2	11	7	38	5	x	27	x
Heerstraße.....	2	16	2	16		x		x
Westend.....	2	8	7	26	5	x	18	x
Schloß Charlottenburg.....	3	13	7	30	4	x	17	x
Mierendorffplatz.....	5	35	3	21	- 2	x	- 14	x
Otto-Suhr-Allee.....	6	24	5	19	- 1	x	- 5	x
Neue Kantstraße.....	2	9	4	17	2	x	8	x
Kantstraße.....	3	15	3	14		x	- 1	x
Kurfürstendamm.....	1	7	1	7		x		x
Halensee.....	3	21	3	21		x		x
Grunewald.....		-	3	16	3	x	16	x
Schmargendorf.....	1	7		-	- 1	x	- 7	x
Wiesbadener Straße.....	1	6	2	11	1	x	5	x
Düsseldorfer Straße.....	6	20	4	13	- 2	x	- 7	x
Barstraße.....	3	22	1	7	- 2	x	- 15	x
Volkspark Wilmersdorf.....	4	12	10	30	6	x	18	x
Forst Grunewald.....	1		1			x		
nicht zuzuordnen.....			1					

Bezirk Berlin Spandau

Brandstiftung (Häufigkeitszahl)

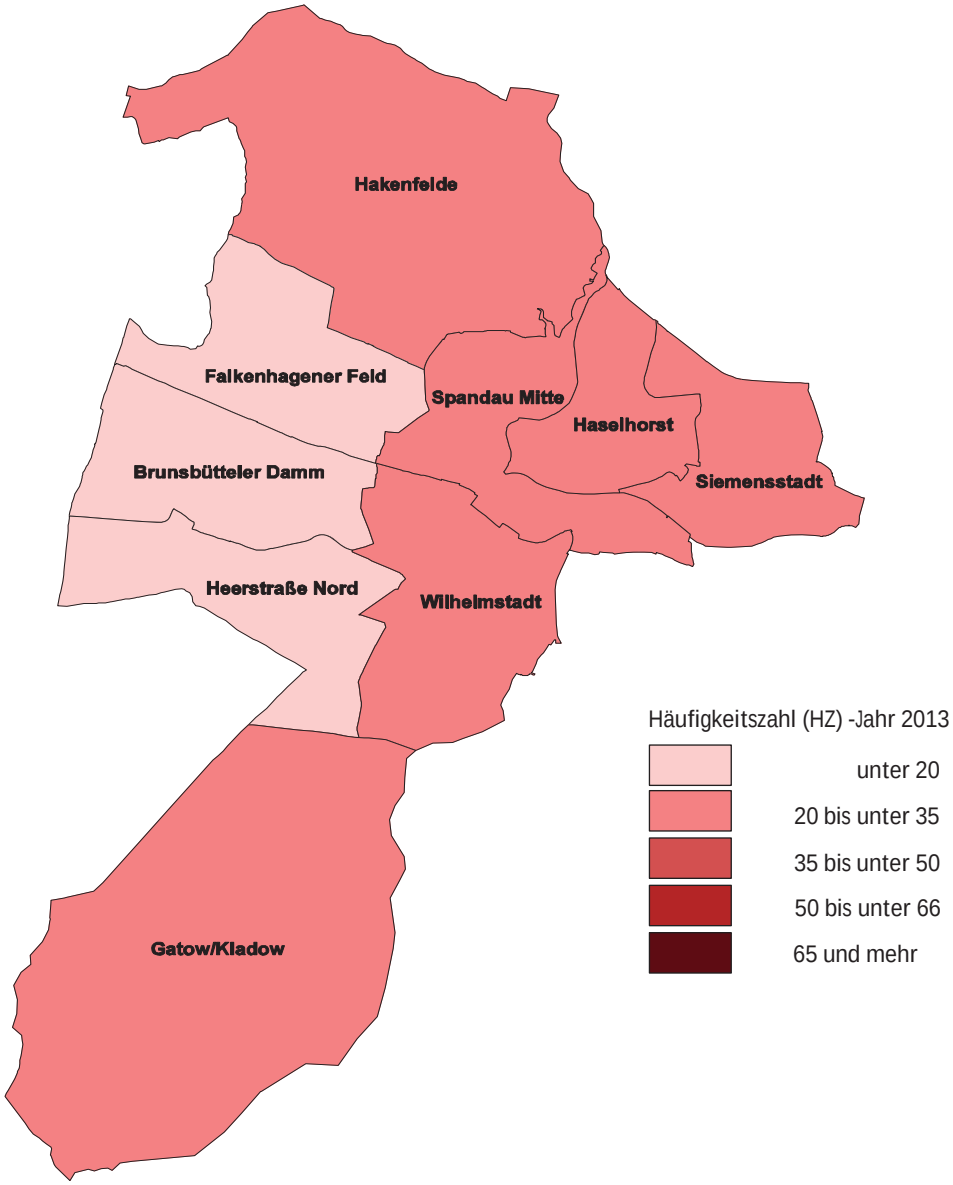

Brandstiftung (PKS-Schlüssel 640000)

Bezirksregion	Jahr 2012		Jahr 2013		Zu-/Abnahme			
	erfasste Fälle	HZ	erfasste Fälle	HZ	Fälle		HZ	
					absolut	in %	absolut	in %
Hakenfelde.....	3	13	6	26	3	x	13	x
Falkenhagener Feld.....	11	28	5	13	- 6	x	- 15	x
Spandau Mitte.....	7	21	8	24	1	x	3	x
Brunsbütteler Damm.....	3	13	2	9	- 1	x	- 4	x
Heerstraße Nord.....	15	56	3	11	- 12	x	- 45	x
Wilhelmstadt.....	10	30	8	23	- 2	x	- 7	x
Haselhorst.....	1	7	3	21	2	x	14	x
Siemensstadt.....	4	34	4	33		x	- 1	x
Gatow/Kladow.....	5	28	5	28		x		x
nicht zuzuordnen.....	2		1					

Bezirk Berlin Steglitz-Zehlendorf

Brandstiftung (Häufigkeitszahl)

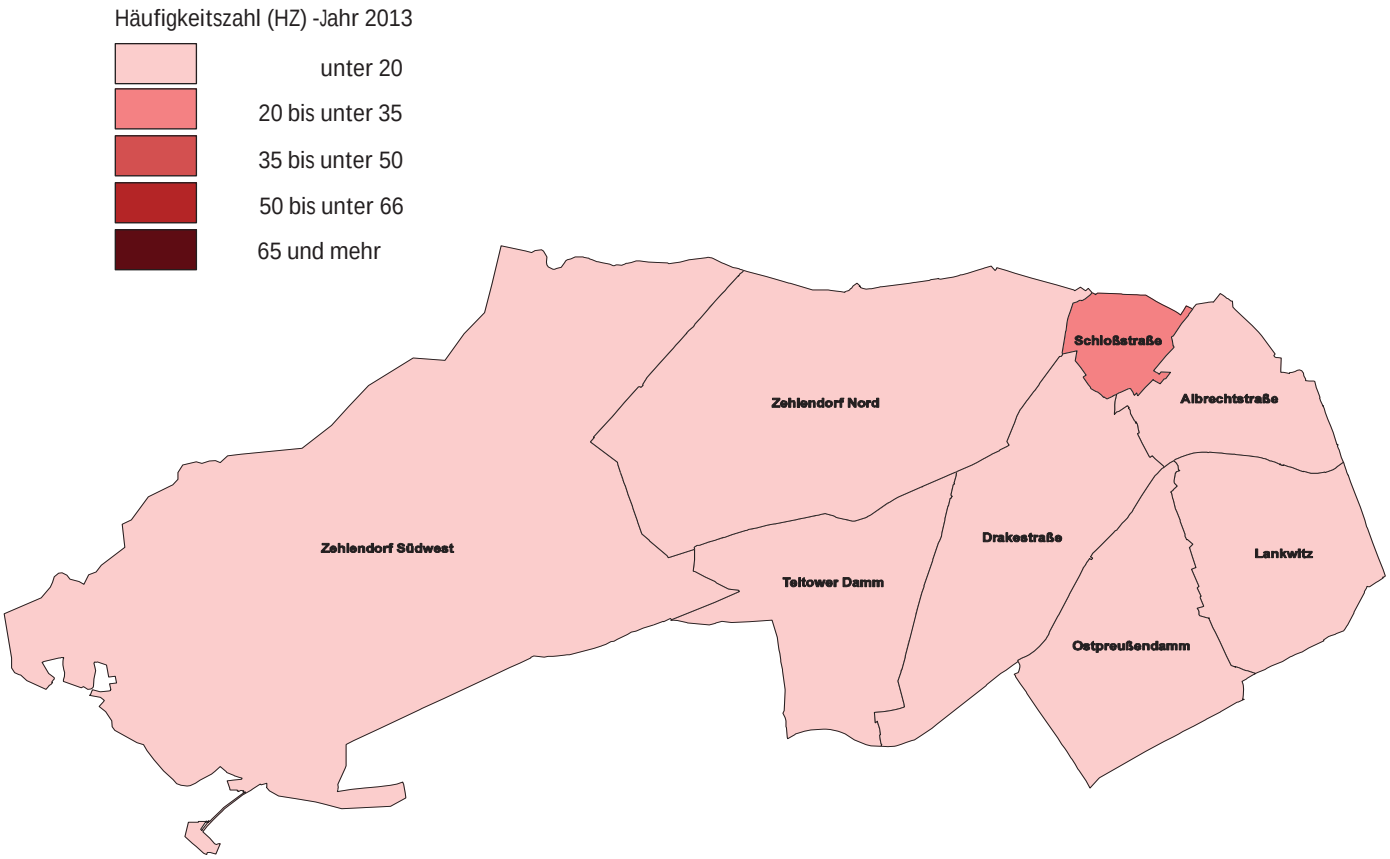

Brandstiftung (PKS-Schlüssel 640000)

Bezirksregion	Jahr 2012		Jahr 2013		Zu-/Abnahme			
	erfasste Fälle	HZ	erfasste Fälle	HZ	Fälle		HZ	
					absolut	in %	absolut	in %
Schloßstraße.....	1	5	5	23	4	x	18	x
Albrechtstraße.....	8	16	6	12	- 2	x	- 4	x
Lankwitz.....	3	7	6	14	3	x	7	x
Ostpreußendamm.....	5	14	6	17	1	x	3	x
Teltower Damm.....	2	6	4	12	2	x	6	x
Drakestraße.....	8	18	8	17		x	- 1	x
Zehlendorf Südwest.....	6	24	2	8	- 4	x	- 16	x
Zehlendorf Nord.....	6	14	2	5	- 4	x	- 9	x
nicht zuzuordnen.....			1					

Bezirk Berlin Tempelhof-Schöneberg

Brandstiftung (Häufigkeitszahl)

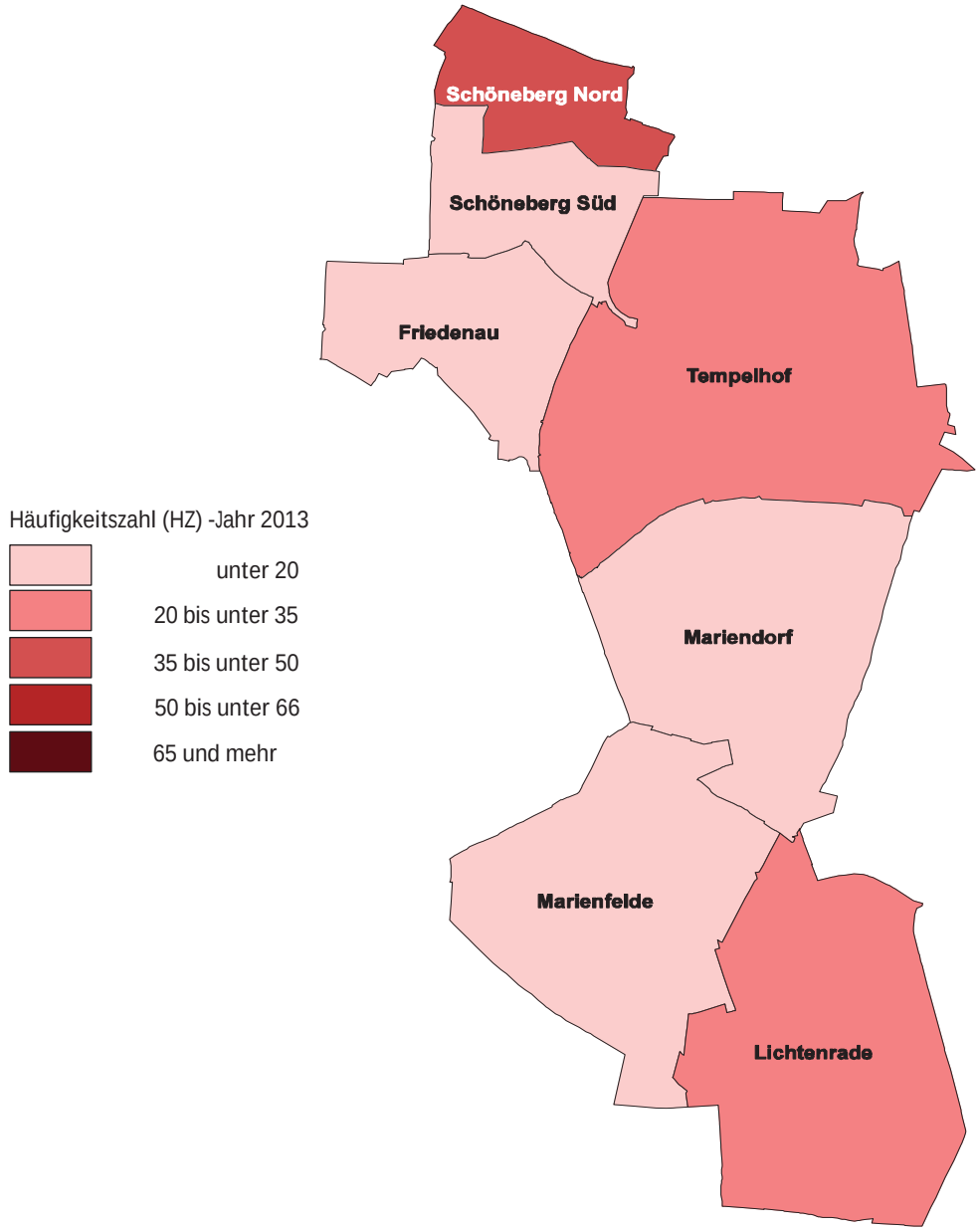

Brandstiftung (PKS-Schlüssel 640000)

Bezirksregion	Jahr 2012		Jahr 2013		Zu-/Abnahme			
	erfasste Fälle	HZ	erfasste Fälle	HZ	Fälle absolut	Fälle in %	HZ absolut	HZ in %
Schöneberg Nord.....	11	23	19	40	8	x	17	x
Schöneberg Süd.....	11	23	9	19	- 2	x	- 4	x
Friedenau.....	8	18	7	16	- 1	x	- 2	x
Tempelhof.....	20	34	13	22	- 7	x	- 12	x
Mariendorf.....	8	16	5	10	- 3	x	- 6	x
Marienfelde.....	5	16	3	10	- 2	x	- 6	x
Lichtenrade.....	6	12	10	20	4	x	8	x
nicht zuzuordnen.....			1					

Bezirk Berlin Neukölln

Brandstiftung (Häufigkeitszahl)

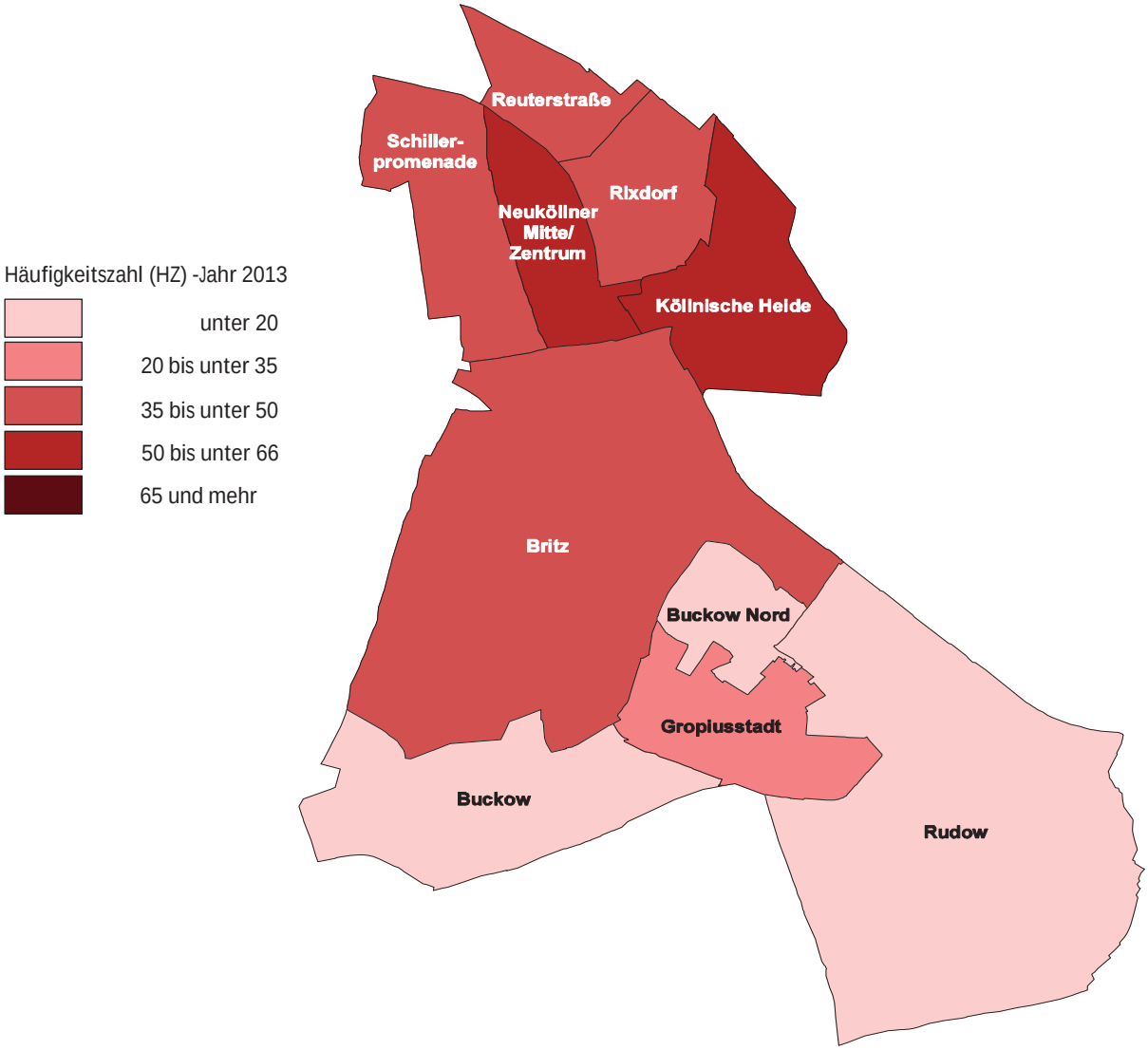

Brandstiftung (PKS-Schlüssel 640000)

Bezirksregion	Jahr 2012		Jahr 2013		Zu-/Abnahme			
	erfasste Fälle	HZ	erfasste Fälle	HZ	Fälle absolut	Fälle in %	HZ absolut	HZ in %
Schillerpromenade	18	58	13	41	- 5	x	- 17	x
Neuköllner Mitte/Zentrum	24	65	19	50	- 5	x	- 15	x
Reuterstraße	11	28	14	35	3	x	7	x
Rixdorf	16	41	15	38	- 1	x	- 3	x
Köllnische Heide	4	27	8	53	4	x	26	x
Britz	12	30	15	37	3	x	7	x
Buckow	3	11	3	11		x		x
Gropiusstadt	1	3	11	30	10	x	27	x
Buckow Nord	1	11	1	11		x		x
Rudow	4	10	3	7	- 1	x	- 3	x
nicht zuzuordnen	1							

Bezirk Berlin Treptow-Köpenick

Brandstiftung (Häufigkeitszahl)

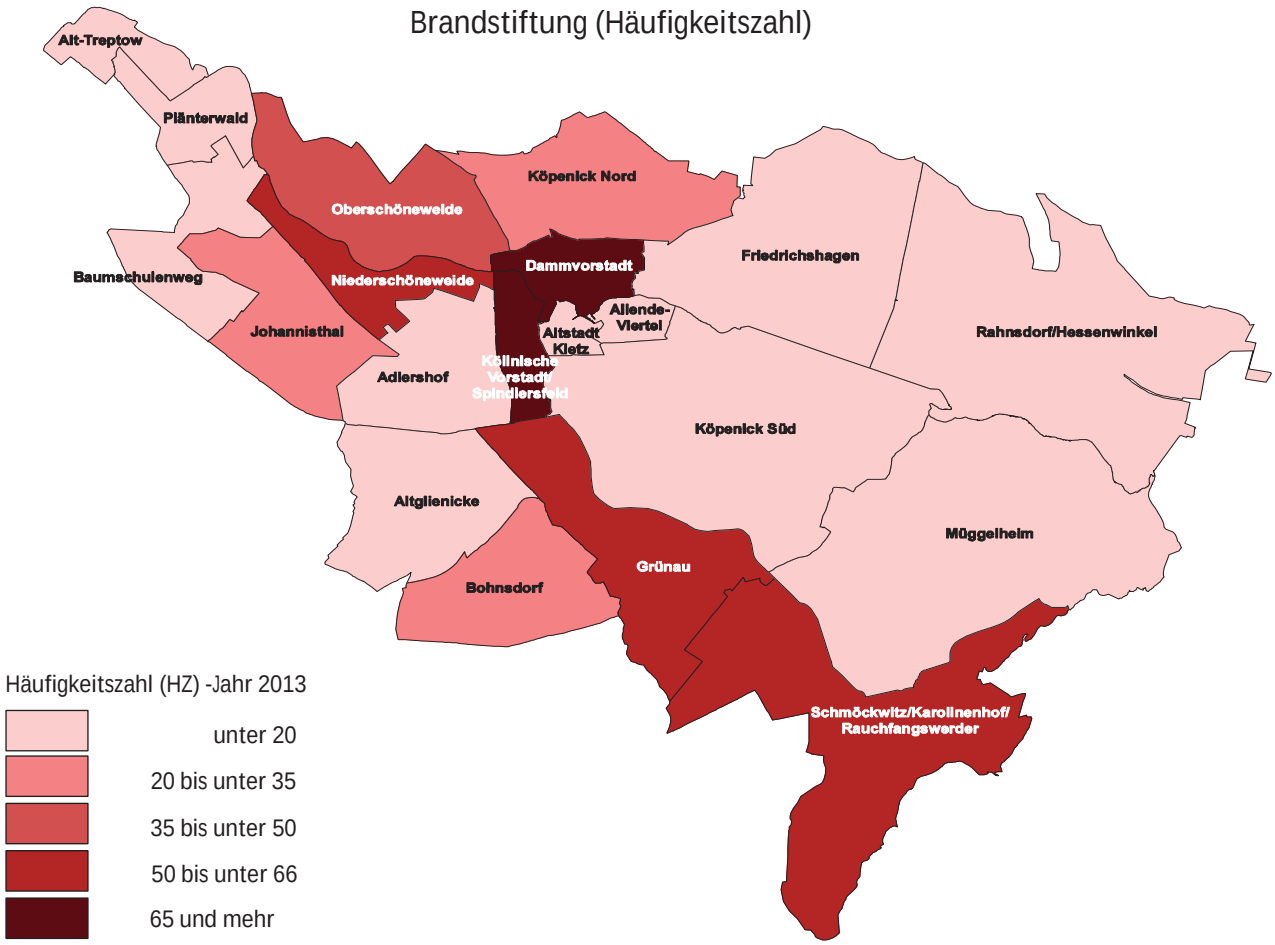

Brandstiftung (PKS-Schlüssel 640000)

Bezirksregion	Jahr 2012		Jahr 2013		Zu-/Abnahme			
	erfasste Fälle	HZ	erfasste Fälle	HZ	Fälle		HZ	
					absolut	in %	absolut	in %
Alt-Treptow	2	18	1	9	- 1	x	- 9	x
Plänterwald	2	19	1	9	- 1	x	- 10	x
Baumschulenweg	4	23	3	17	- 1	x	- 6	x
Johannisthal	2	11	4	22	2	x	11	x
Oberschöneweide	12	63	8	41	- 4	x	- 22	x
Niederschöneweide	5	48	6	56	1	x	8	x
Adlershof	6	39	3	19	- 3	x	- 20	x
Kölln. Vorstadt/Spindlersf.	2	20	14	140	12	x	120	x
Altglienicke	2	8	3	12	1	x	4	x
Bohnsdorf	1	8	3	25	2	x	17	x
Grünau	1	19	3	54	2	x	35	x
Schmöckwitz/Karolinenhof	3	74	2	50	- 1	x	- 24	x
Köpenick Süd	3	19	3	19		x		x
Allende-Viertel		-		-		x		x
Altstadt Kietz	3	44	1	14	- 2	x	- 30	x
Müggelheim	1	15	1	15		x		x
Friedrichshagen	1	6	2	11	1	x	5	x
Rahnsdorf/Hessenwinkel		-	1	11	1	x	11	x
Dammvorstadt	7	74	12	126	5	x	52	x
Köpenick Nord		-	3	24	3	x	24	x
nicht zuzuordnen	3		2					

Bezirk Berlin Marzahn-Hellersdorf

Brandstiftung (Häufigkeitszahl)

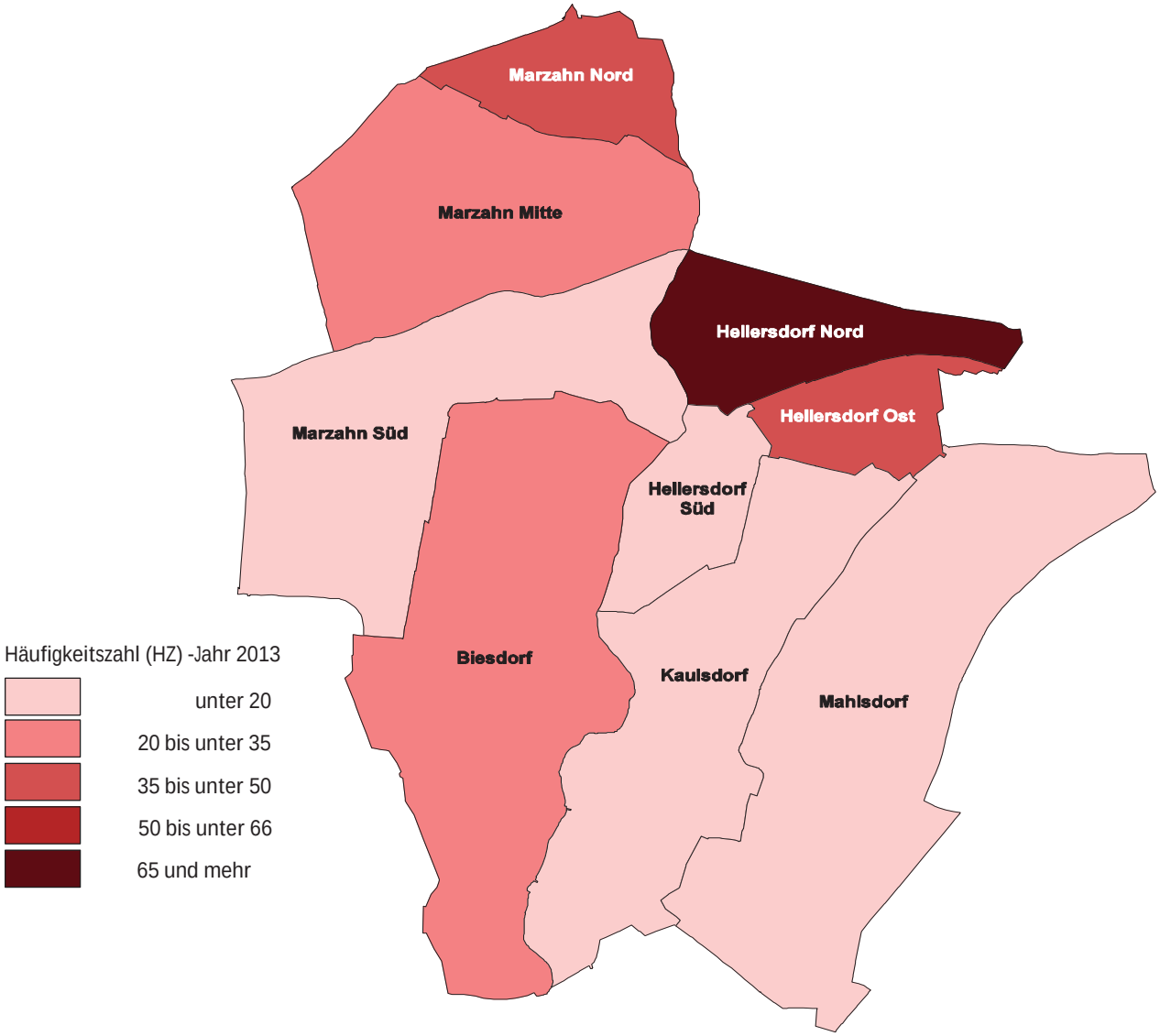

Brandstiftung (PKS-Schlüssel 640000)

Bezirksregion	Jahr 2012		Jahr 2013		Zu-/Abnahme			
	erfasste Fälle	HZ	erfasste Fälle	HZ	Fälle		HZ	
					absolut	in %	absolut	in %
Marzahn Nord	10	44	11	48	1	x	4	x
Marzahn Mitte	20	44	15	33	- 5	x	- 11	x
Marzahn Süd	19	53	7	19	- 12	x	- 34	x
Hellersdorf Nord	16	49	26	78	10	x	29	x
Hellersdorf Ost	5	27	9	48	4	x	21	x
Hellersdorf Süd	3	12	3	12		x		x
Biesdorf	1	4	8	31	7	x	27	x
Kaulsdorf	1	5	3	16	2	x	11	x
Mahlsdorf	2	7		-	- 2	x	- 7	x
nicht zuzuordnen								

Bezirk Berlin Lichtenberg

Brandstiftung (Häufigkeitszahl)

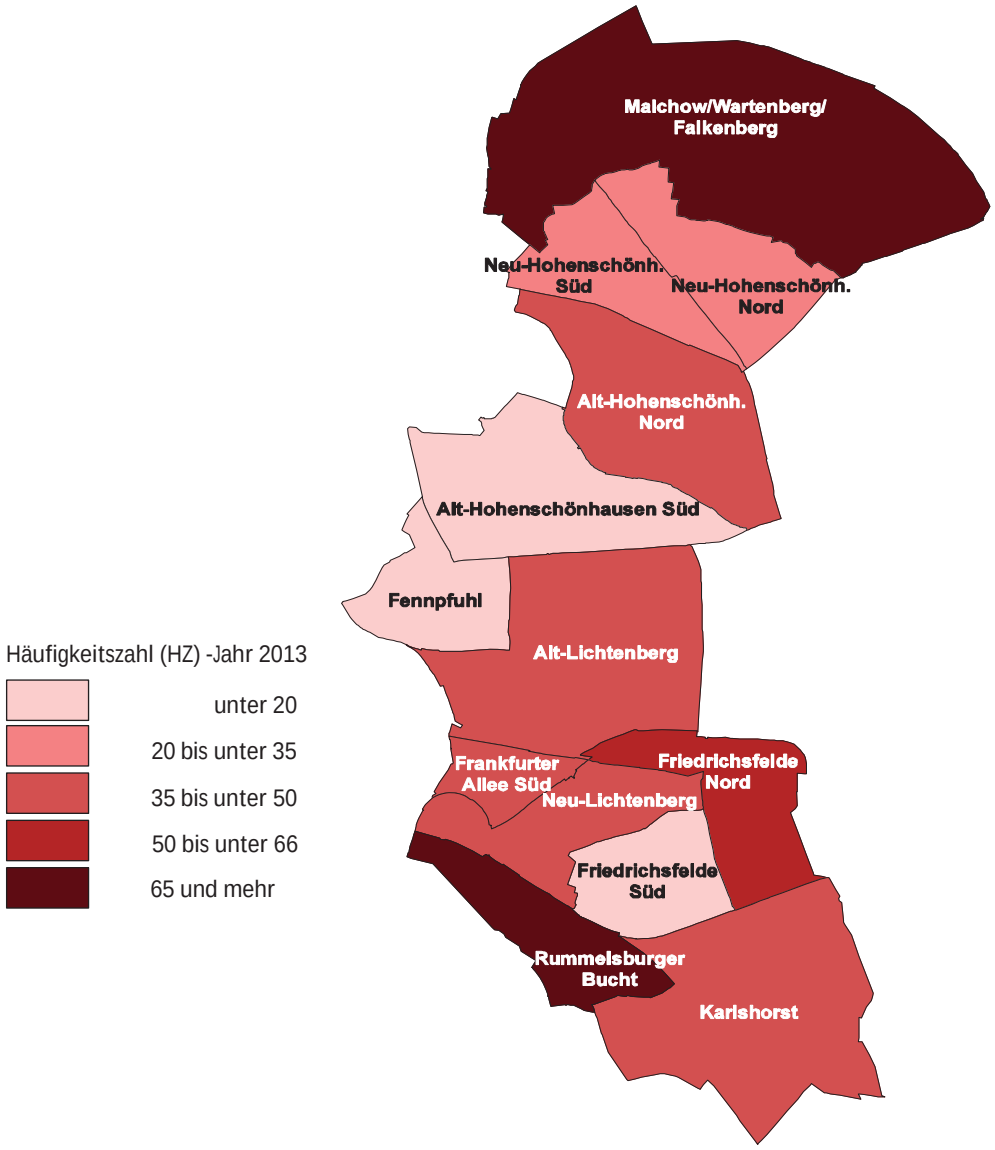

Brandstiftung (PKS-Schlüssel 640000)

Bezirksregion	Jahr 2012		Jahr 2013		Zu-/Abnahme			
					Fälle		HZ	
	erfasste Fälle	HZ	erfasste Fälle	HZ	absolut	in %	absolut	in %
Malchow/Warten-/Falkenberg.....	5	119	4	94	- 1	x	- 25	(- 21,0)
Neu-Hohenschönhausen Nord.....	7	25	7	25		x		x
Neu-Hohenschönhausen Süd.....	3	12	6	23	3	x	11	x
Alt-Hohenschönhausen Nord.....	3	22	6	44	3	x	22	x
Alt-Hohenschönhausen Süd.....	6	20	4	14	- 2	x	- 6	x
Fennpfuhl.....	8	25	4	12	- 4	x	- 13	x
Alt-Lichtenberg.....	11	46	11	44		x	- 2	x
Frankfurter Allee Süd.....	2	21	4	40	2	x	19	x
Neu-Lichtenberg.....	9	31	14	47	5	x	16	x
Friedrichsfelde Nord.....	2	15	7	52	5	x	37	x
Friedrichsfelde Süd.....	3	12	3	12		x		x
Rummelsburger Bucht.....	6	184	10	302	4	x	118	(64,1)
Karlshorst.....	2	9	11	47	9	x	38	x
nicht zuzuordnen.....								

Bezirk Berlin Reinickendorf

Brandstiftung (Häufigkeitszahl)

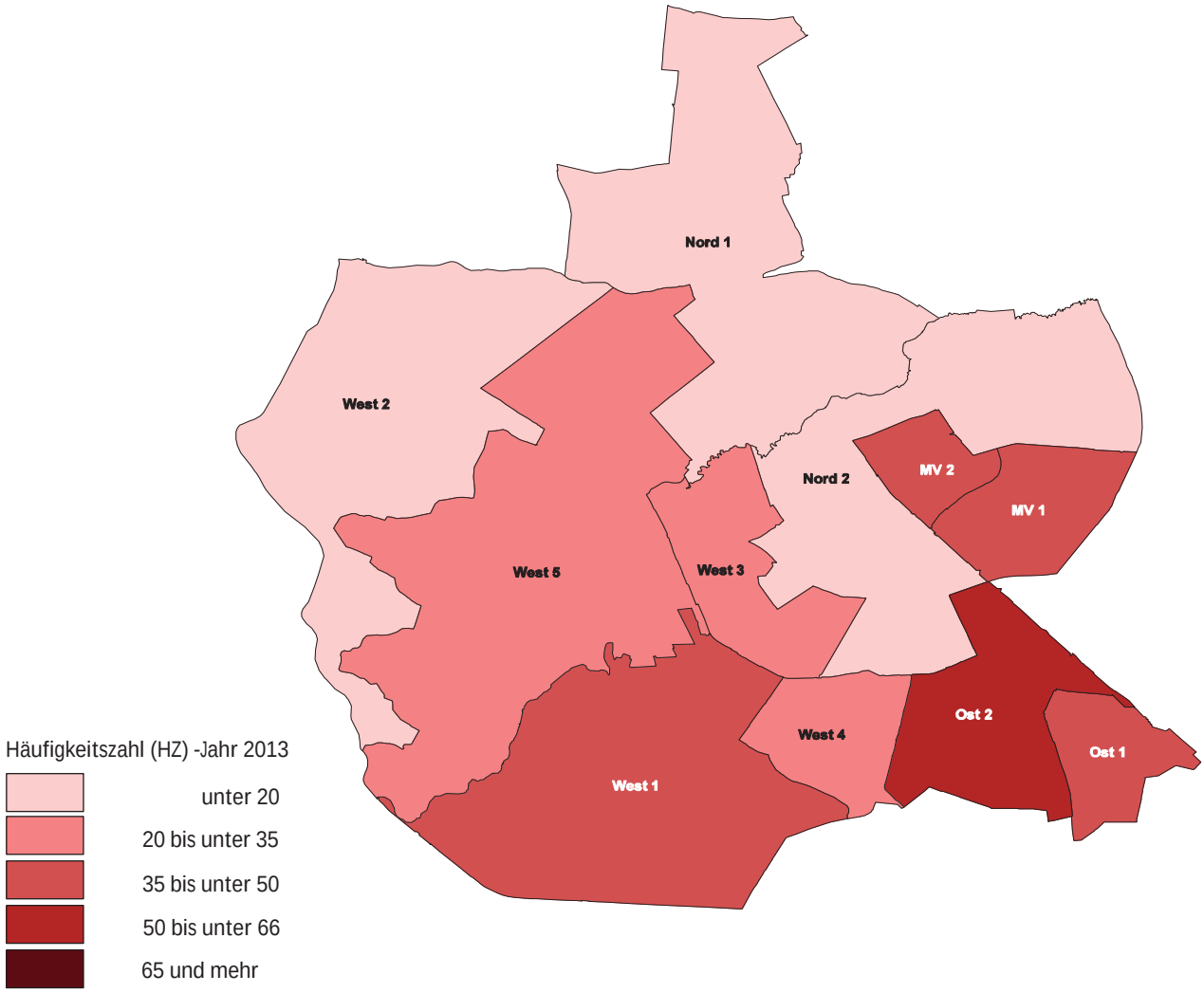

Brandstiftung (PKS-Schlüssel 640000)

Bezirksregion	Jahr 2012		Jahr 2013		Zu-/Abnahme			
	erfasste Fälle	HZ	erfasste Fälle	HZ	Fälle absolut	Fälle in %	HZ absolut	HZ in %
Ost 1	4	16	10	38	6	x	22	x
Ost 2	10	39	13	50	3	x	11	x
West 1	1	7	7	48	6	x	41	x
West 4	8	32	8	31		x	- 1	x
West 5		-	3	29	3	x	29	x
West 2	6	25	4	17	- 2	x	- 8	x
Nord 1	4	12	1	3	- 3	x	- 9	x
Nord 2	4	14	4	13		x	- 1	x
MV 1	18	51	18	49		x	- 2	x
MV 2	1	12	4	47	3	x	35	x
West 3	2	13	5	31	3	x	18	x
nicht zuzuordnen	5		6					

Berlin - Sachbeschädigung -insgesamt (Häufigkeitszahl)

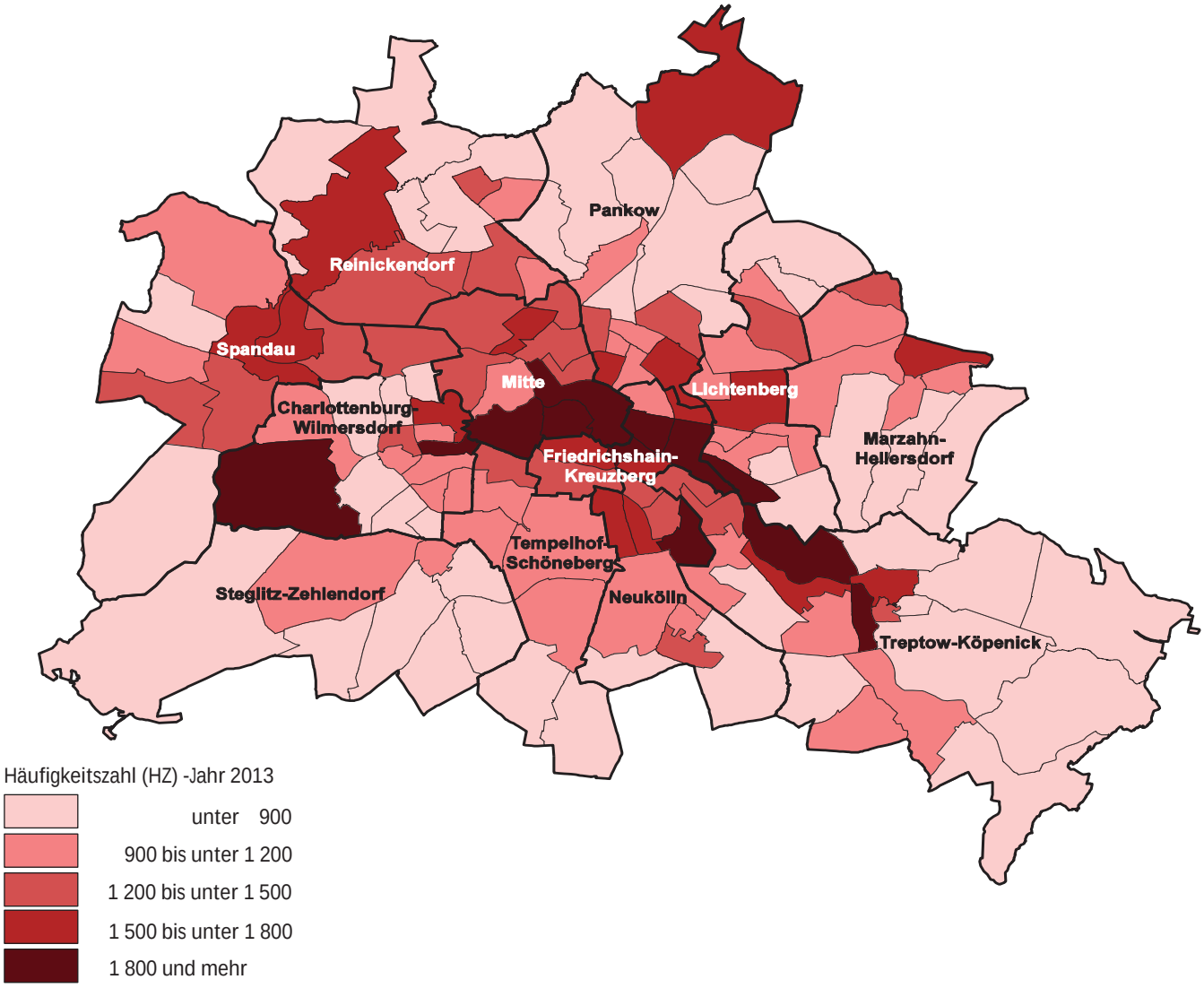

Sachbeschädigung -insgesamt- (PKS-Schlüssel 674000)

Bezirk	Jahr 2012		Jahr 2013		Zu-/Abnahme			
	erfasste Fälle	HZ	erfasste Fälle	HZ	Fälle absolut	Fälle in %	HZ absolut	HZ in %
Mitte	6 180	1 842	5 744	1 672	- 436	- 7,1	- 170	- 9,2
Friedrichshain-Kreuzberg	5 499	2 061	5 094	1 878	- 405	- 7,4	- 183	- 8,9
Pankow	4 722	1 286	4 096	1 096	- 626	- 13,3	- 190	- 14,8
Charlottenburg-Wilmersdorf	3 975	1 255	3 759	1 172	- 216	- 5,4	- 83	- 6,6
Spandau	3 257	1 471	2 920	1 301	- 337	- 10,3	- 170	- 11,6
Steglitz-Zehlendorf	3 082	1 048	2 537	856	- 545	- 17,7	- 192	- 18,3
Tempelhof-Schöneberg	3 907	1 194	3 465	1 052	- 442	- 11,3	- 142	- 11,9
Neukölln	4 558	1 444	4 313	1 346	- 245	- 5,4	- 98	- 6,8
Treptow-Köpenick	3 317	1 369	2 822	1 153	- 495	- 14,9	- 216	- 15,8
Marzahn-Hellersdorf	3 435	1 372	2 818	1 114	- 617	- 18,0	- 258	- 18,8
Lichtenberg	3 355	1 298	2 909	1 108	- 446	- 13,3	- 190	- 14,6
Reinickendorf	3 295	1 340	2 699	1 083	- 596	- 18,1	- 257	- 19,2
Berlin, nicht zuzuordnen	852		305					
Berlin -Gesamt-	**49 434**	**1 466**	**43 481**	**1 277**	**- 5 953**	**-12,0**	**- 189**	**-12,9**

Bezirk Berlin Mitte

Sachbeschädigung -insgesamt (Häufigkeitszahl)

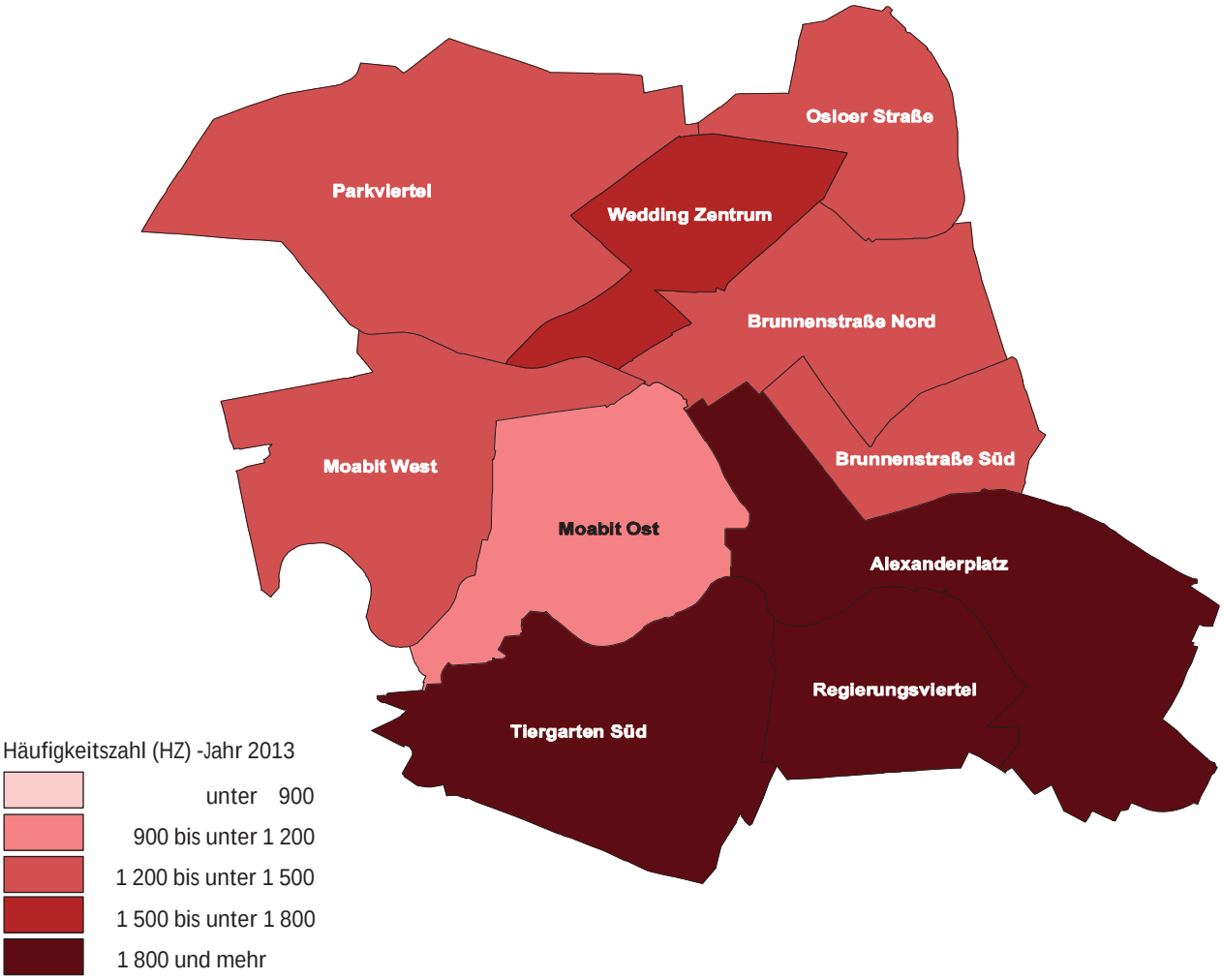

Sachbeschädigung -insgesamt- (PKS-Schlüssel 674000)

Bezirksregion	Jahr 2012		Jahr 2013		Zu-/Abnahme			
	erfasste Fälle	HZ	erfasste Fälle	HZ	Fälle absolut	Fälle in %	HZ absolut	HZ in %
Tiergarten Süd	273	2 167	263	2 022	- 10	- 3,7	- 145	- 6,7
Regierungsviertel	380	4 145	355	3 818	- 25	- 6,6	- 327	- 7,9
Alexanderplatz	1 538	3 259	1 301	2 703	- 237	- 15,4	- 556	- 17,1
Brunnenstraße Süd	428	1 674	366	1 378	- 62	- 14,5	- 296	- 17,7
Moabit West	516	1 232	532	1 244	16	3,1	12	1,0
Moabit Ost	392	1 125	418	1 184	26	6,6	59	5,2
Osloer Straße	521	1 487	441	1 218	- 80	- 15,4	- 269	- 18,1
Brunnenstraße Nord	495	1 403	454	1 267	- 41	- 8,3	- 136	- 9,7
Parkviertel	568	1 370	541	1 277	- 27	- 4,8	- 93	- 6,8
Wedding Zentrum	806	1 534	822	1 519	16	2,0	- 15	- 1,0
nicht zuzuordnen	263	-	251	-				

Bezirk Berlin Friedrichshain-Kreuzberg

Sachbeschädigung -insgesamt (Häufigkeitszahl)

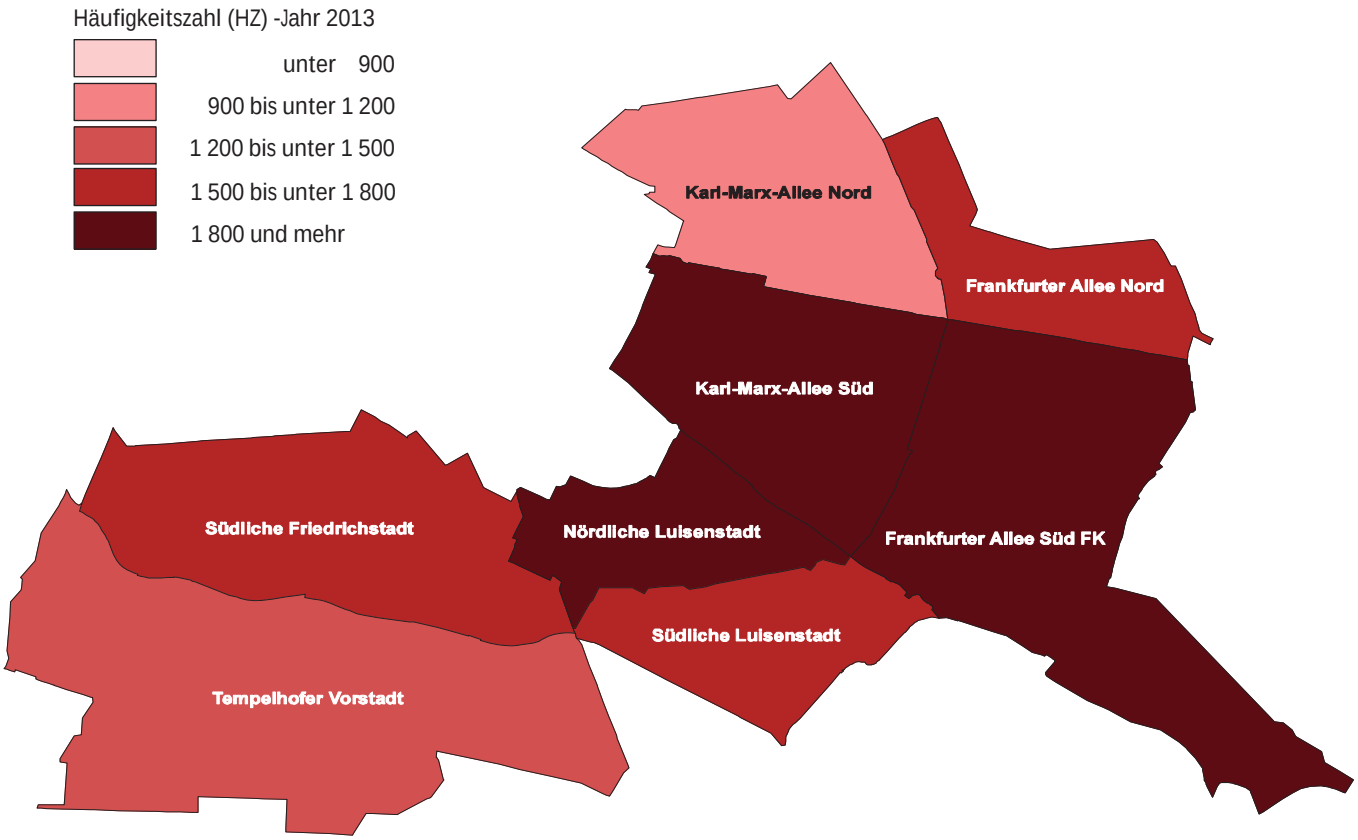

Sachbeschädigung -insgesamt- (PKS-Schlüssel 674000)

Bezirksregion	Jahr 2012		Jahr 2013		Zu-/Abnahme			
	erfasste Fälle	HZ	erfasste Fälle	HZ	Fälle		HZ	
					absolut	in %	absolut	in %
Südliche Friedrichstadt.....	700	1 797	639	1 617	- 61	- 8,7	- 180	- 10,0
Tempelhofer Vorstadt.....	915	1 502	805	1 299	- 110	- 12,0	- 203	- 13,5
Nördliche Luisenstadt.....	456	2 041	510	2 262	54	11,8	221	10,8
Südliche Luisenstadt.....	441	1 690	468	1 770	27	6,1	80	4,7
Karl-Marx-Allee Nord.....	356	1 599	255	1 134	- 101	- 28,4	- 465	- 29,1
Karl-Marx-Allee Süd.....	537	2 341	530	2 264	- 7	- 1,3	- 77	- 3,3
Frankfurter Allee Nord.....	534	1 966	440	1 594	- 94	- 17,6	- 372	- 18,9
Frankfurter Allee Süd FK.....	1 171	2 535	1 270	2 687	99	8,5	152	6,0
nicht zuzuordnen.....	389		177					

Bezirk Berlin Pankow

Sachbeschädigung -insgesamt (Häufigkeitszahl)

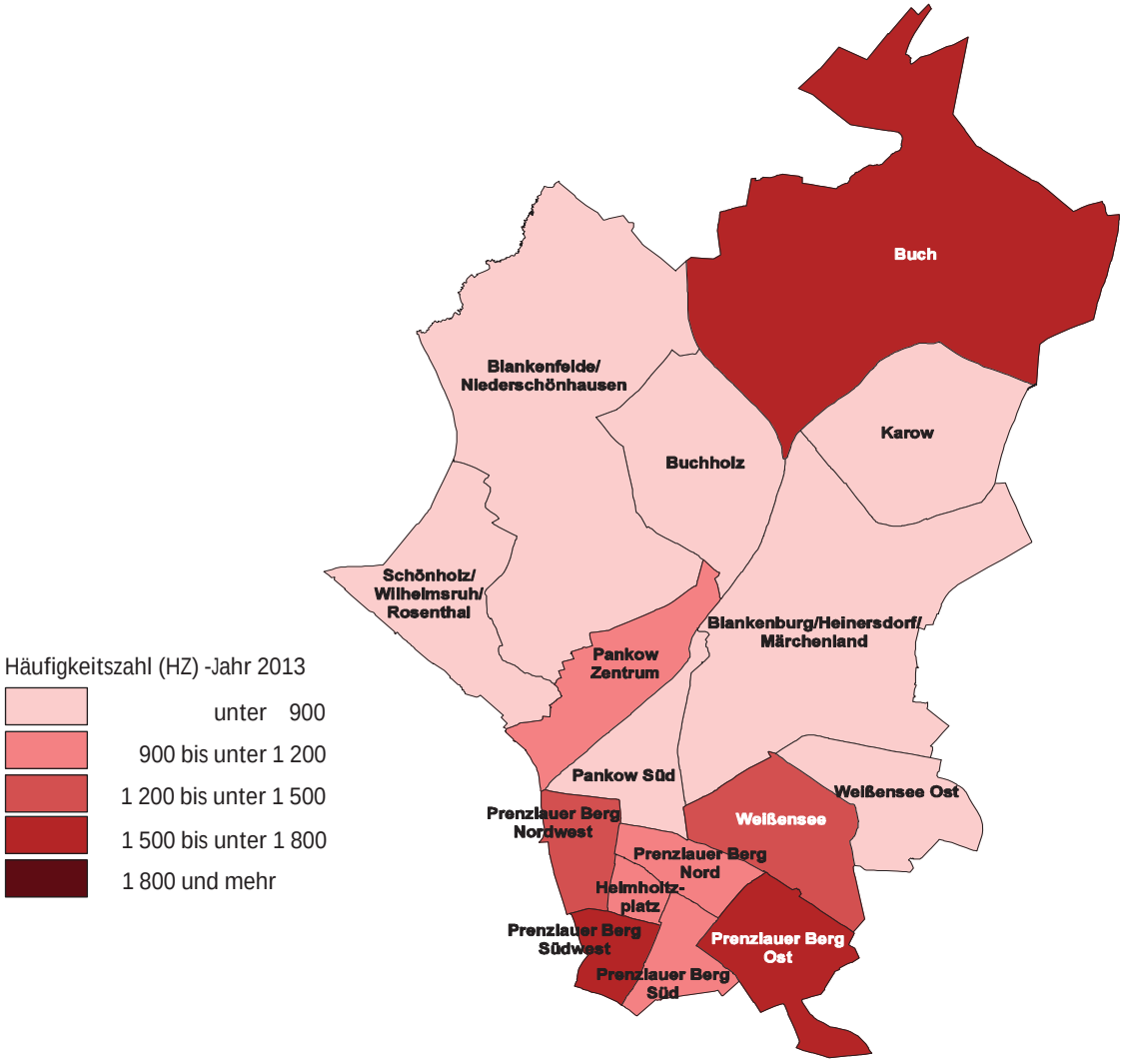

Sachbeschädigung -insgesamt- (PKS-Schlüssel 674000)

Bezirksregion	Jahr 2012		Jahr 2013		Zu-/Abnahme			
	erfasste Fälle	HZ	erfasste Fälle	HZ	Fälle absolut	Fälle in %	HZ absolut	HZ in %
Buch	191	1 465	210	1 550	19	9,9	85	5,8
Blankenfelde/Niederschönhausen	215	849	180	693	- 35	- 16,3	- 156	- 18,4
Buchholz	114	679	130	765	16	14,0	86	12,7
Karow	118	631	88	473	- 30	- 25,4	- 158	- 25,0
Blankenburg/Heinersdorf	154	1 090	119	842	- 35	- 22,7	- 248	- 22,8
Pankow Süd	298	936	230	708	- 68	- 22,8	- 228	- 24,4
Schönholz/Wilhelmsruh/Rosenthal	143	835	80	466	- 63	- 44,1	- 369	- 44,2
Pankow Zentrum	382	1 177	337	1 011	- 45	- 11,8	- 166	- 14,1
Weißensee	486	1 475	425	1 264	- 61	- 12,6	- 211	- 14,3
Weißensee Ost	205	1 366	132	872	- 73	- 35,6	- 494	- 36,2
Prenzlauer Berg Nordwest	339	1 435	325	1 340	- 14	- 4,1	- 95	- 6,6
Prenzlauer Berg Nord	282	1 093	254	974	- 28	- 9,9	- 119	- 10,9
Helmholtzplatz	261	1 231	238	1 098	- 23	- 8,8	- 133	- 10,8
Prenzlauer Berg Ost	439	1 807	430	1 733	- 9	- 2,1	- 74	- 4,1
Prenzlauer Berg Südwest	536	2 211	403	1 624	- 133	- 24,8	- 587	- 26,5
Prenzlauer Berg Süd	409	1 328	327	1 050	- 82	- 20,0	- 278	- 20,9
nicht zuzuordnen	150		188					

Bezirk Berlin Charlottenburg-Wilmersdorf

Sachbeschädigung -insgesamt (Häufigkeitszahl)

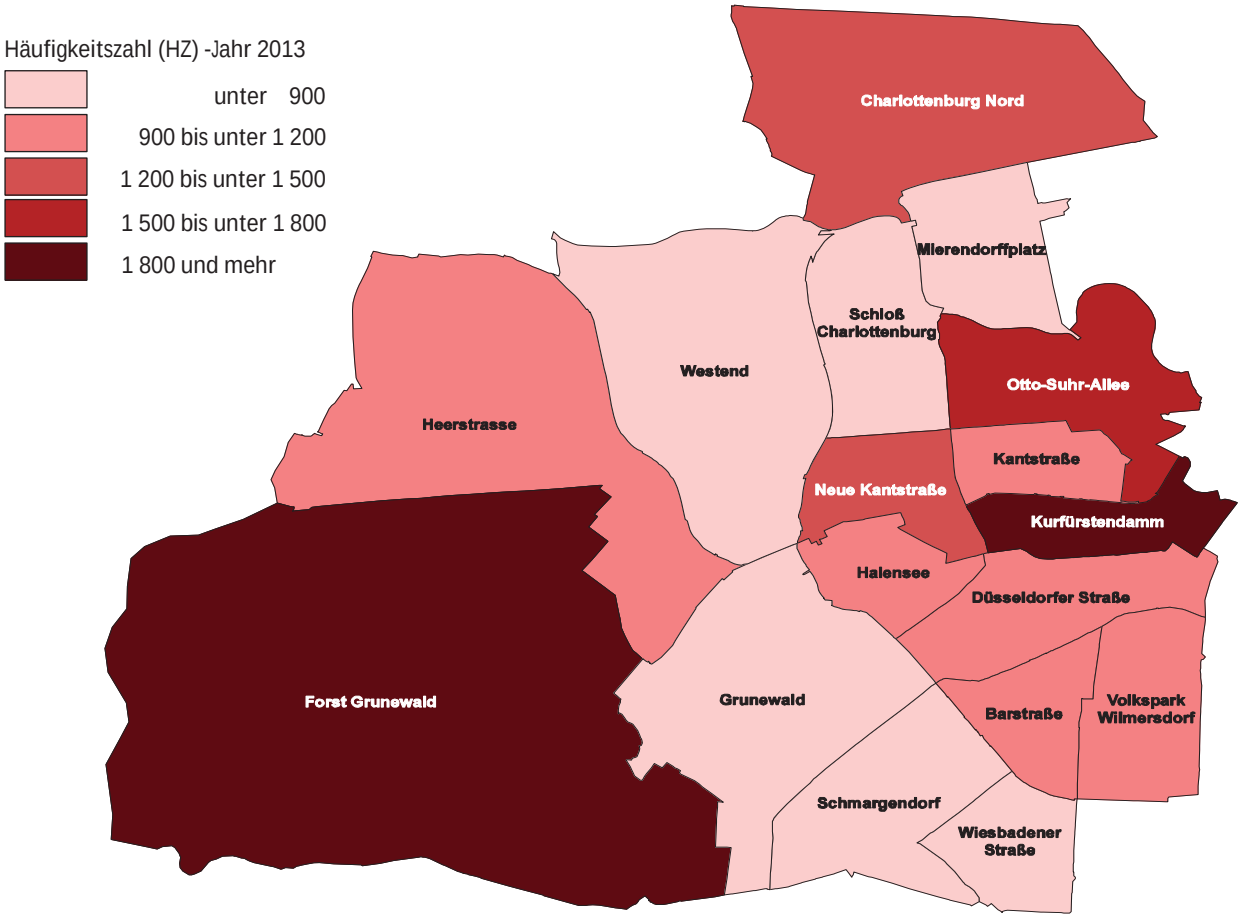

Sachbeschädigung -insgesamt- (PKS-Schlüssel 674000)

Bezirksregion	Jahr 2012		Jahr 2013		Zu-/Abnahme			
	erfasste Fälle	HZ	erfasste Fälle	HZ	Fälle absolut	Fälle in %	HZ absolut	HZ in %
Charlottenburg Nord.....	245	1 354	230	1 246	- 15	- 6,1	- 108	- 8,0
Heerstraße.....	141	1 128	143	1 134	2	1,4	6	0,5
Westend.....	317	1 211	226	848	- 91	- 28,7	- 363	- 30,0
Schloß Charlottenburg.....	231	998	186	794	- 45	- 19,5	- 204	- 20,4
Mierendorffplatz.....	150	1 054	130	891	- 20	- 13,3	- 163	- 15,5
Otto-Suhr-Allee.....	436	1 711	410	1 590	- 26	- 6,0	- 121	- 7,1
Neue Kantstraße.....	169	737	290	1 251	121	71,6	514	69,7
Kantstraße.....	234	1 143	211	1 018	- 23	- 9,8	- 125	- 10,9
Kurfürstendamm.....	405	2 781	342	2 345	- 63	- 15,6	- 436	- 15,7
Halensee.....	149	1 050	167	1 158	18	12,1	108	10,3
Grunewald.....	128	715	123	675	- 5	- 3,9	- 40	- 5,6
Schmargendorf.....	104	753	110	791	6	5,8	38	5,0
Wiesbadener Straße.....	143	793	140	775	- 3	- 2,1	- 18	- 2,3
Düsseldorfer Straße.....	376	1 282	330	1 109	- 46	- 12,2	- 173	- 13,5
Barstraße.....	151	1 119	143	1 054	- 8	- 5,3	- 65	- 5,8
Volkspark Wilmersdorf.....	303	936	303	924		-	- 12	- 1,3
Forst Grunewald.....	11		21		10	x		
nicht zuzuordnen.....	282		254					

Bezirk Berlin Spandau

Sachbeschädigung -insgesamt (Häufigkeitszahl)

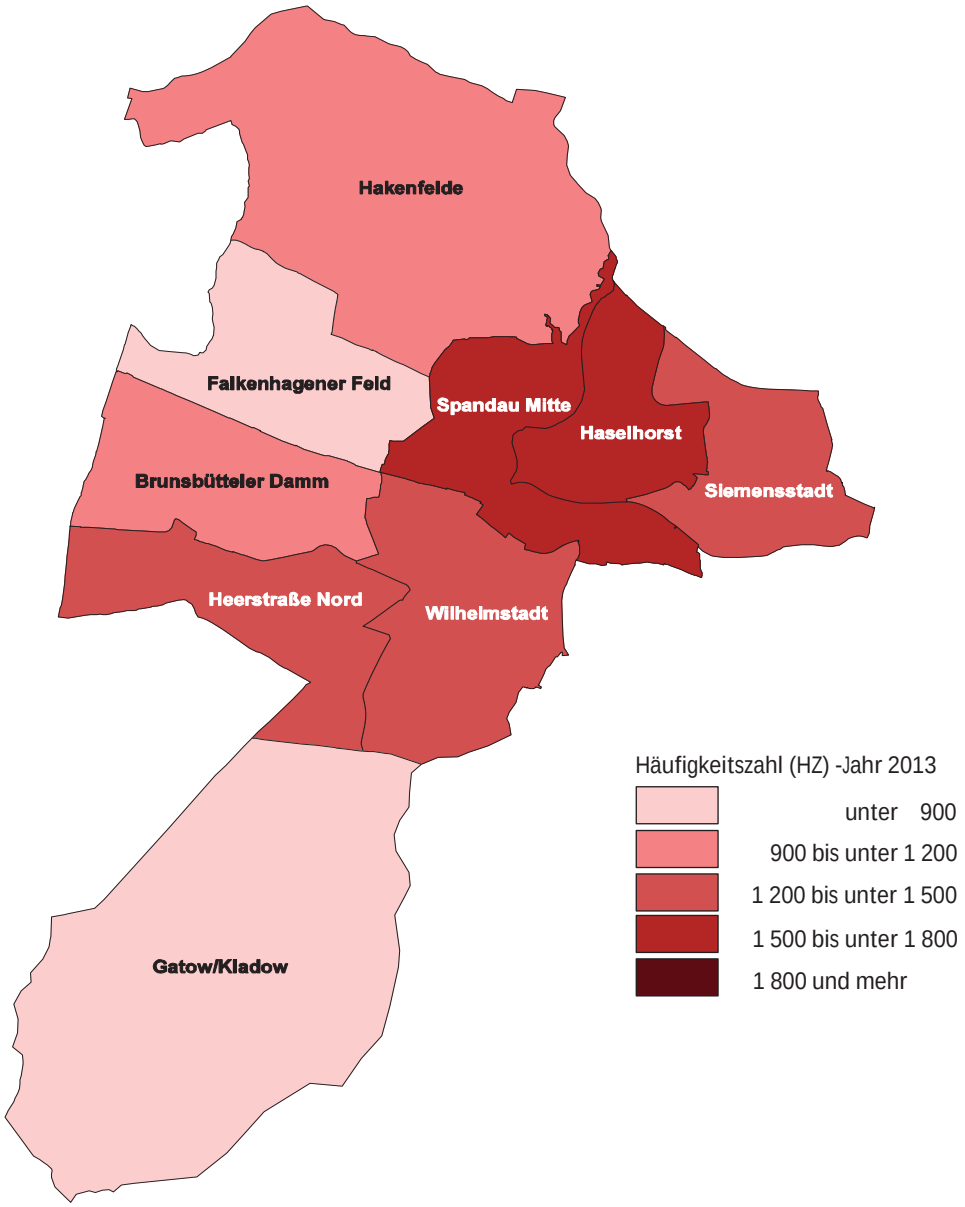

Sachbeschädigung -insgesamt- (PKS-Schlüssel 674000)

Bezirksregion	Jahr 2012		Jahr 2013		Zu-/Abnahme			
	erfasste Fälle	HZ	erfasste Fälle	HZ	Fälle		HZ	
					absolut	in %	absolut	in %
Hakenfelde.....	239	1 055	222	978	- 17	- 7,1	- 77	- 7,3
Falkenhagener Feld.....	430	1 102	351	895	- 79	- 18,4	- 207	- 18,8
Spandau Mitte.....	593	1 805	602	1 786	9	1,5	- 19	- 1,1
Brunsbütteler Damm.....	221	955	229	991	8	3,6	36	3,8
Heerstraße Nord.....	427	1 600	352	1 314	- 75	- 17,6	- 286	- 17,9
Wilhelmstadt.....	568	1 676	480	1 397	- 88	- 15,5	- 279	- 16,6
Haselhorst.....	261	1 896	238	1 649	- 23	- 8,8	- 247	- 13,0
Siemensstadt.....	167	1 437	155	1 293	- 12	- 7,2	- 144	- 10,0
Gatow/Kladow.....	131	737	141	777	10	7,6	40	5,4
nicht zuzuordnen.....	220		150					

Bezirk Berlin Steglitz-Zehlendorf

Sachbeschädigung -insgesamt (Häufigkeitszahl)

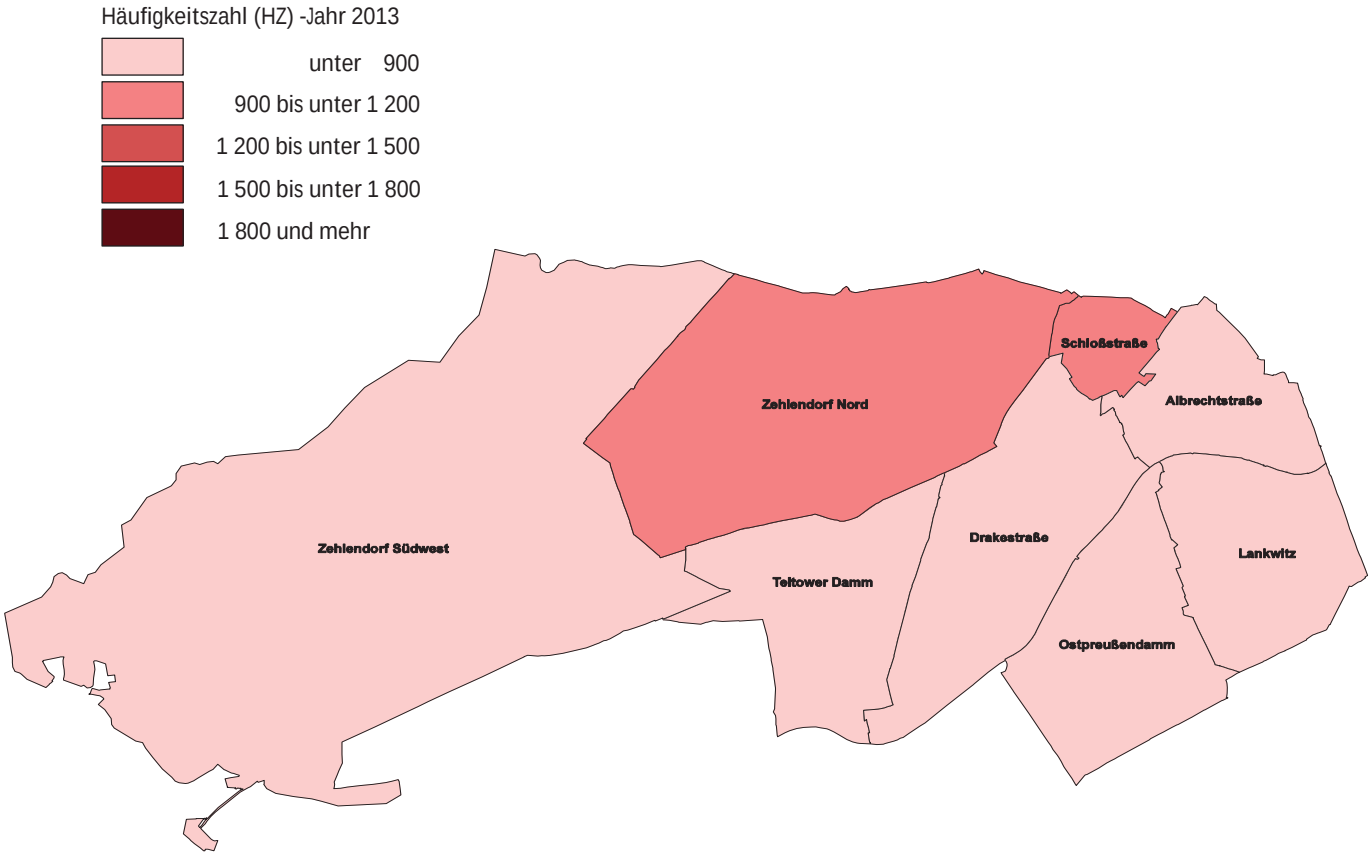

Sachbeschädigung -insgesamt- (PKS-Schlüssel 674000)

Bezirksregion	Jahr 2012		Jahr 2013		Zu-/Abnahme			
	erfasste Fälle	HZ	erfasste Fälle	HZ	Fälle		HZ	
					absolut	in %	absolut	in %
Schloßstraße.....	255	1 192	235	1 087	- 20	- 7,8	- 105	- 8,8
Albrechtstraße.....	439	855	332	641	- 107	- 24,4	- 214	- 25,0
Lankwitz.....	383	926	364	871	- 19	- 5,0	- 55	- 5,9
Ostpreußendamm.....	310	894	235	672	- 75	- 24,2	- 222	- 24,8
Teltower Damm.....	339	1 037	254	775	- 85	- 25,1	- 262	- 25,3
Drakestraße.....	346	757	289	621	- 57	- 16,5	- 136	- 18,0
Zehlendorf Südwest.....	248	972	215	842	- 33	- 13,3	- 130	- 13,4
Zehlendorf Nord.....	538	1 296	404	973	- 134	- 24,9	- 323	- 24,9
nicht zuzuordnen.....	224		209					

Bezirk Berlin Tempelhof-Schöneberg

Sachbeschädigung -insgesamt (Häufigkeitszahl)

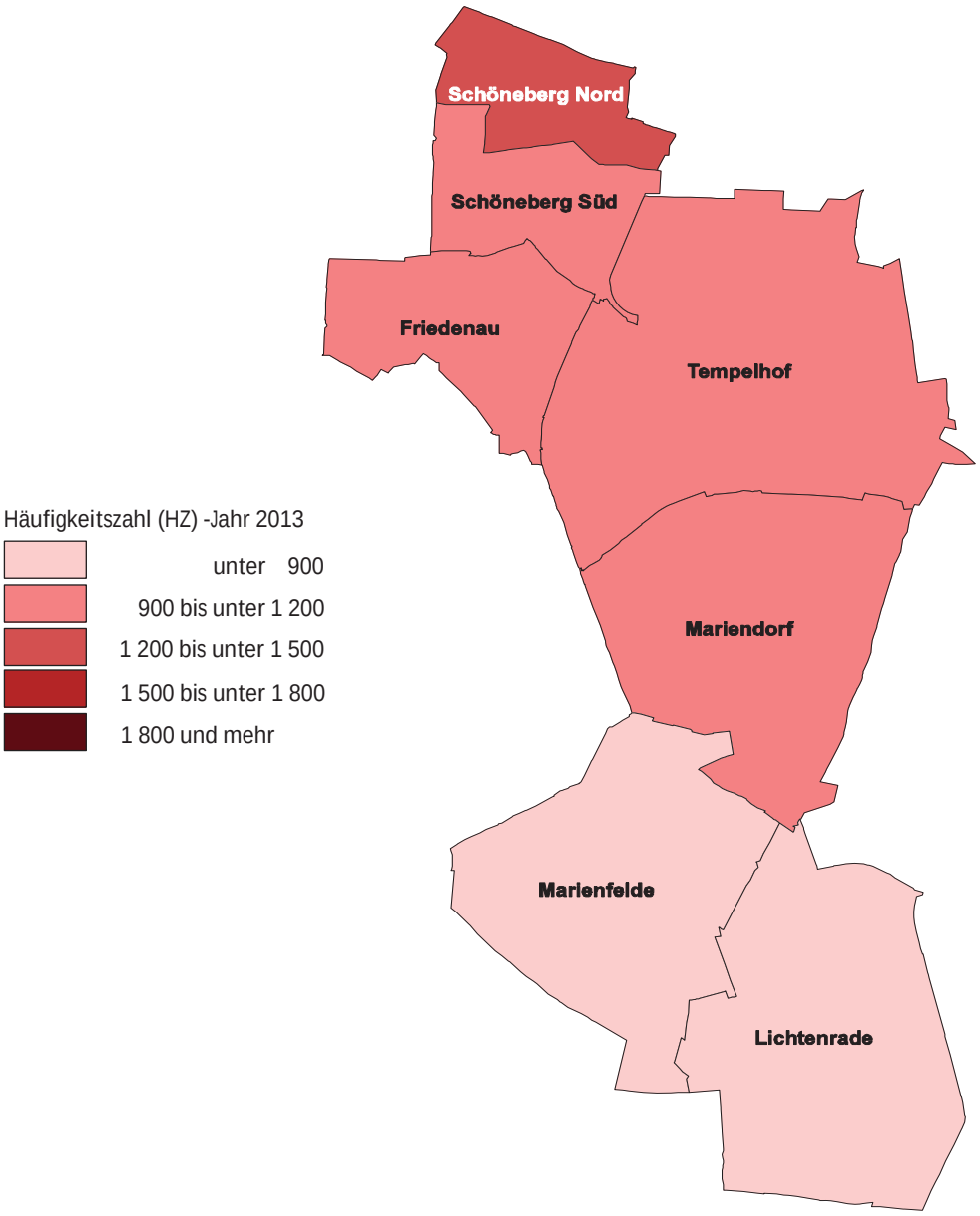

Sachbeschädigung -insgesamt- (PKS-Schlüssel 674000)

Bezirksregion	Jahr 2012		Jahr 2013		Zu-/Abnahme			
	erfasste Fälle	HZ	erfasste Fälle	HZ	Fälle absolut	Fälle in %	HZ absolut	HZ in %
Schöneberg Nord	729	1 548	681	1 451	- 48	- 6,6	- 97	- 6,3
Schöneberg Süd	545	1 147	518	1 086	- 27	- 5,0	- 61	- 5,3
Friedenau	426	968	402	905	- 24	- 5,6	- 63	- 6,5
Tempelhof	813	1 379	703	1 171	- 110	- 13,5	- 208	- 15,1
Mariendorf	501	1 006	493	986	- 8	- 1,6	- 20	- 2,0
Marienfelde	276	907	225	737	- 51	- 18,5	- 170	- 18,7
Lichtenrade	472	955	338	680	- 134	- 28,4	- 275	- 28,8
nicht zuzuordnen	145		105					

Bezirk Berlin Neukölln

Sachbeschädigung -insgesamt (Häufigkeitszahl)

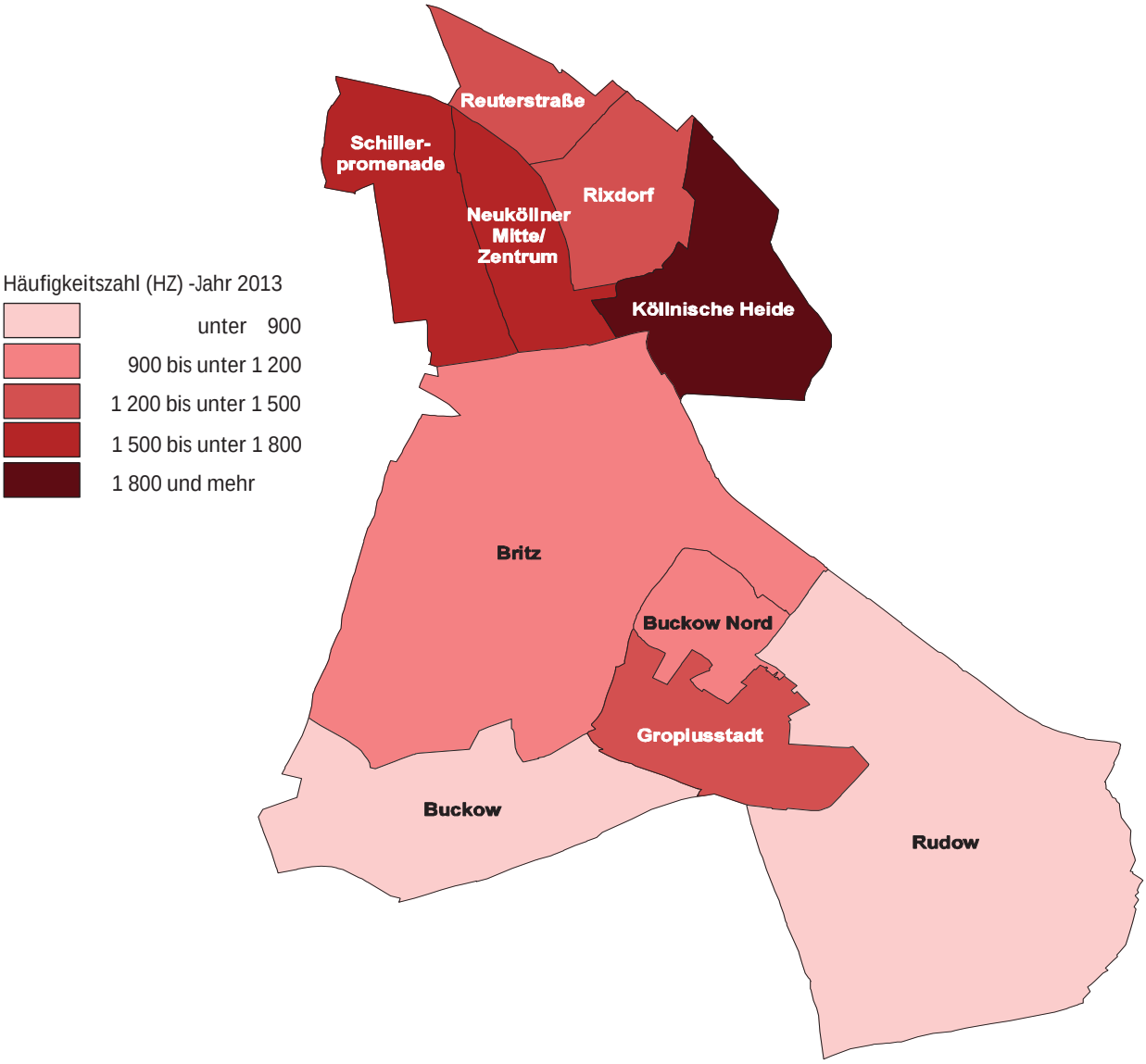

Sachbeschädigung -insgesamt- (PKS-Schlüssel 674000)

Bezirksregion	Jahr 2012		Jahr 2013		Zu-/Abnahme			
	erfasste Fälle	HZ	erfasste Fälle	HZ	Fälle absolut	Fälle in %	HZ absolut	HZ in %
Schillerpromenade	529	1 710	561	1 777	32	6,0	67	3,9
Neuköllner Mitte/Zentrum	821	2 225	618	1 638	- 203	- 24,7	- 587	- 26,4
Reuterstraße	509	1 311	567	1 426	58	11,4	115	8,8
Rixdorf	550	1 415	509	1 288	- 41	- 7,5	- 127	- 9,0
Köllnische Heide	315	2 137	508	3 378	193	61,3	1 241	58,1
Britz	501	1 237	413	1 005	- 88	- 17,6	- 232	- 18,8
Buckow	281	1 018	227	815	- 54	- 19,2	- 203	- 19,9
Gropiusstadt	525	1 456	479	1 317	- 46	- 8,8	- 139	- 9,5
Buckow Nord	64	688	91	971	27	x	283	(41,1)
Rudow	405	966	288	684	- 117	- 28,9	- 282	- 29,2
nicht zuzuordnen	58		52					

Bezirk Berlin Treptow-Köpenick

Sachbeschädigung -insgesamt (Häufigkeitszahl)

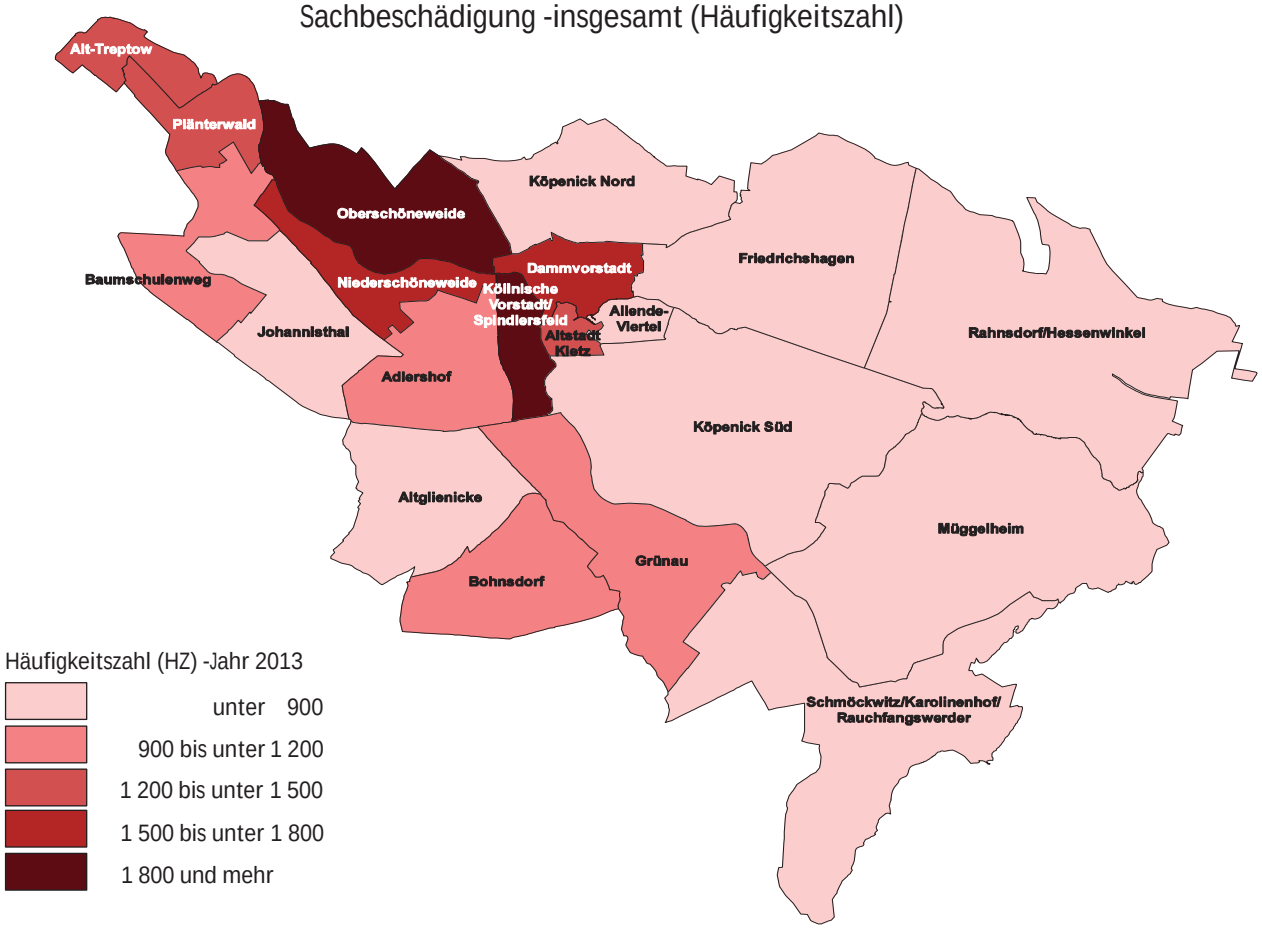

Sachbeschädigung -insgesamt- (PKS-Schlüssel 674000)

Bezirksregion	Jahr 2012		Jahr 2013		Zu-/Abnahme			
	erfasste Fälle	HZ	erfasste Fälle	HZ	Fälle absolut	Fälle in %	HZ absolut	HZ in %
Alt-Treptow	193	1 766	166	1 496	- 27	- 14,0	- 270	- 15,3
Plänterwald	171	1 586	133	1 228	- 38	- 22,2	- 358	- 22,6
Baumschulenweg	248	1 439	167	958	- 81	- 32,7	- 481	- 33,4
Johannisthal	206	1 125	164	890	- 42	- 20,4	- 235	- 20,9
Oberschöneweide	343	1 790	372	1 887	29	8,5	97	5,4
Niederschöneweide	200	1 914	169	1 590	- 31	- 15,5	- 324	- 16,9
Adlershof	222	1 443	158	1 013	- 64	- 28,8	- 430	- 29,8
Kölln. Vorstadt/Spindlersf.	191	1 940	202	2 019	11	5,8	79	4,1
Altglienicke	175	685	130	502	- 45	- 25,7	- 183	- 26,7
Bohnsdorf	93	781	115	953	22	x	172	(22,0)
Grünau	77	1 426	56	999	- 21	x	- 427	(- 29,9)
Schmöckwitz/Karolinenhof	31	763	27	670	- 4	x	- 93	(- 12,2)
Köpenick Süd	135	864	133	855	- 2	- 1,5	- 9	- 1,0
Allende-Viertel	66	1 081	48	784	- 18	x	- 297	(- 27,5)
Altstadt Kietz	123	1 791	88	1 268	- 35	- 28,5	- 523	- 29,2
Müggelheim	46	707	26	397	- 20	x	- 310	(- 43,8)
Friedrichshagen	144	824	112	641	- 32	- 22,2	- 183	- 22,2
Rahnsdorf/Hessenwinkel	41	457	55	614	14	x	157	(34,4)
Dammvorstadt	148	1 570	150	1 575	2	1,4	5	0,3
Köpenick Nord	88	716	73	595	- 15	x	- 121	(- 16,9)
nicht zuzuordnen	376		278					

Bezirk Berlin Marzahn-Hellersdorf

Sachbeschädigung -insgesamt (Häufigkeitszahl)

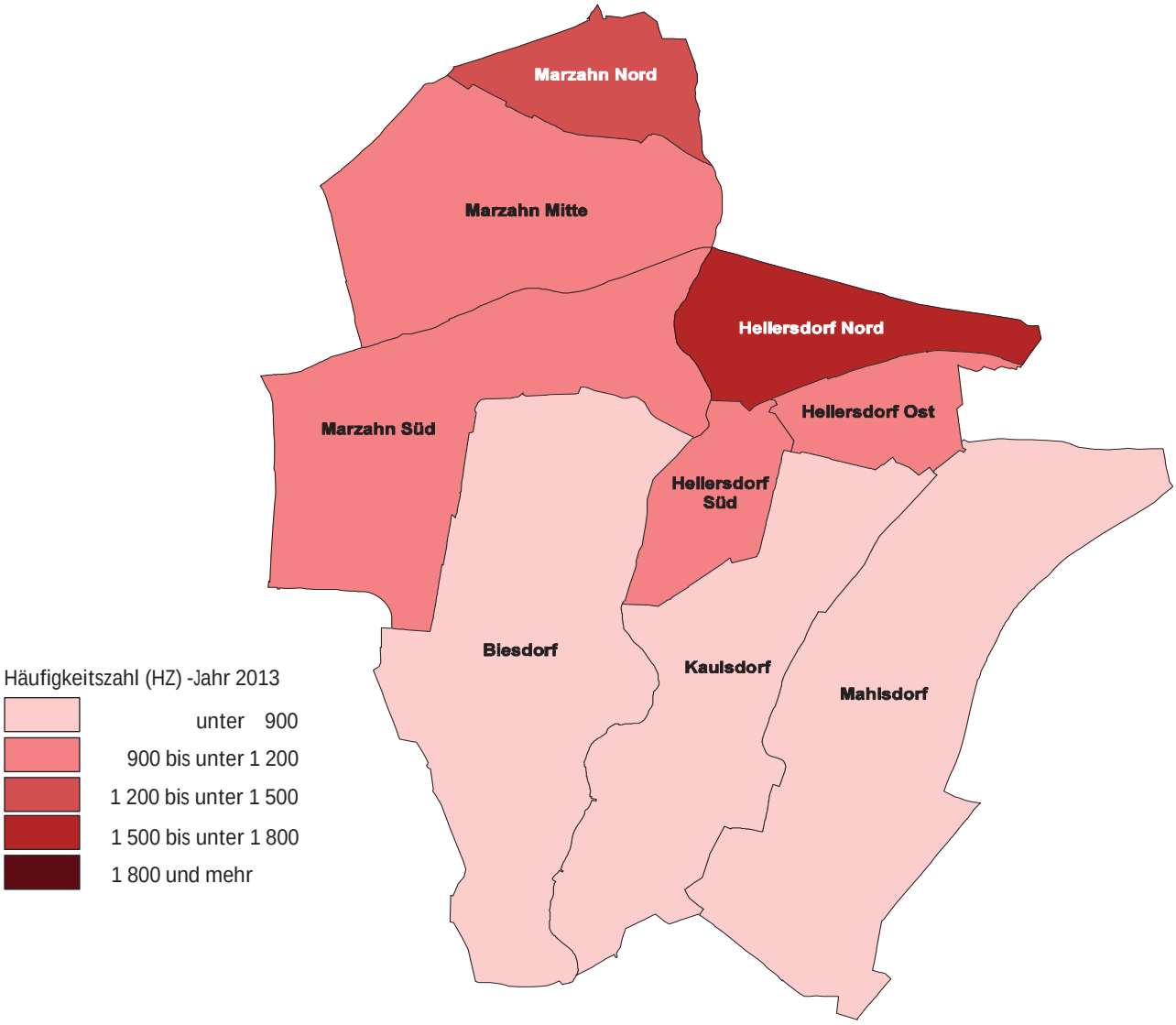

Sachbeschädigung -insgesamt- (PKS-Schlüssel 674000)

Bezirksregion	Jahr 2012		Jahr 2013		Zu-/Abnahme			
	erfasste Fälle	HZ	erfasste Fälle	HZ	Fälle		HZ	
					absolut	in %	absolut	in %
Marzahn Nord	353	1 558	279	1 217	- 74	- 21,0	- 341	- 21,9
Marzahn Mitte	624	1 381	505	1 107	- 119	- 19,1	- 274	- 19,8
Marzahn Süd	411	1 138	356	973	- 55	- 13,4	- 165	- 14,5
Hellersdorf Nord	640	1 952	581	1 745	- 59	- 9,2	- 207	- 10,6
Hellersdorf Ost	336	1 821	224	1 187	- 112	- 33,3	- 634	- 34,8
Hellersdorf Süd	322	1 327	252	1 032	- 70	- 21,7	- 295	- 22,2
Biesdorf	213	847	215	843	2	0,9	- 4	- 0,5
Kaulsdorf	150	802	122	654	- 28	- 18,7	- 148	- 18,5
Mahlsdorf	268	993	130	480	- 138	- 51,5	- 513	- 51,7
nicht zuzuordnen	118		154					

Bezirk Berlin Lichtenberg

Sachbeschädigung -insgesamt (Häufigkeitszahl)

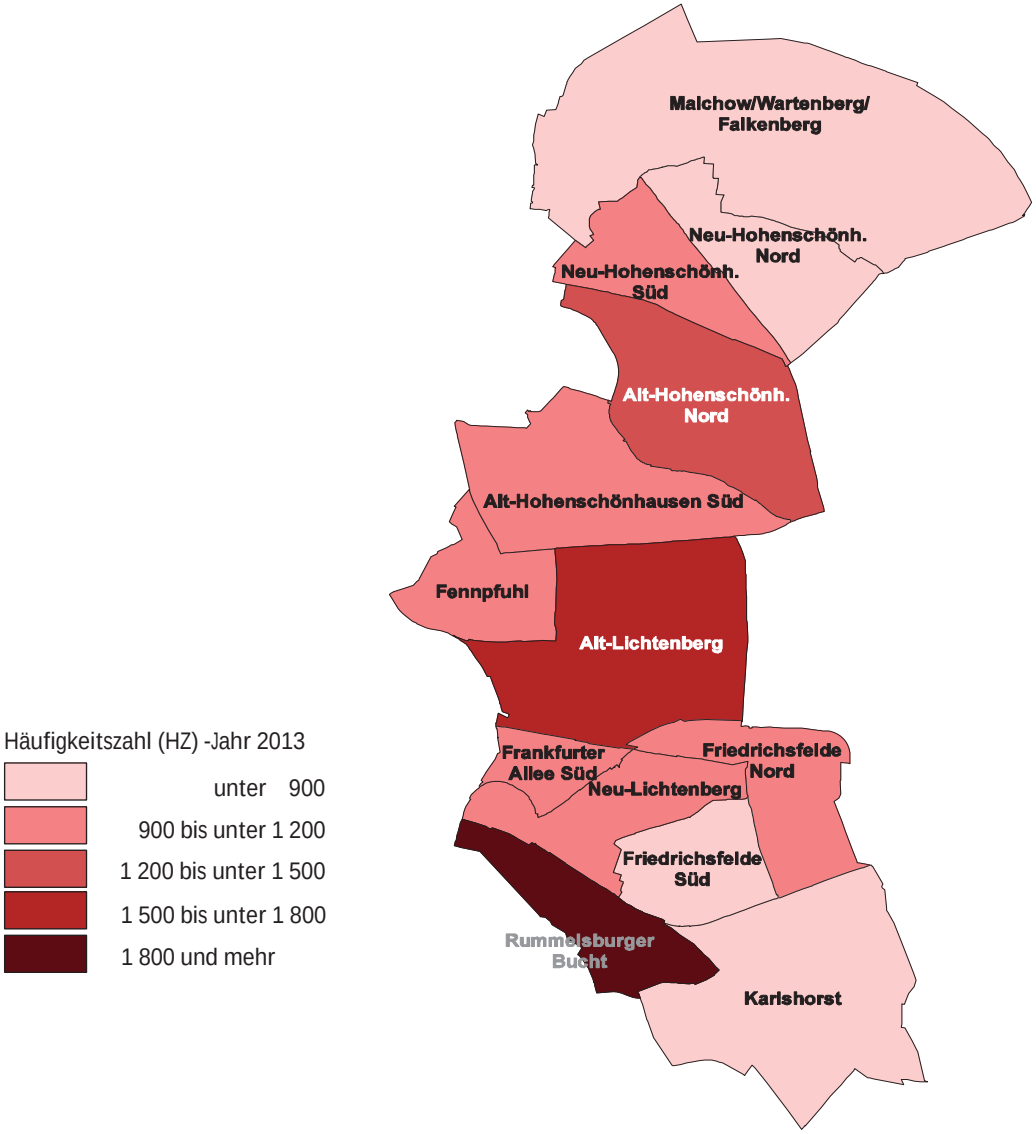

Sachbeschädigung -insgesamt- (PKS-Schlüssel 674000)

Bezirksregion	Jahr 2012		Jahr 2013		Zu-/Abnahme			
	erfasste Fälle	HZ	erfasste Fälle	HZ	Fälle absolut	Fälle in %	HZ absolut	HZ in %
Malchow/Warten-/Falkenberg.....	54	1 288	29	683	- 25	x	- 605	(- 47,0)
Neu-Hohenschönhausen Nord.....	276	1 004	201	726	- 75	- 27,2	- 278	- 27,7
Neu-Hohenschönhausen Süd.....	290	1 121	274	1 060	- 16	- 5,5	- 61	- 5,4
Alt-Hohenschönhausen Nord.....	150	1 113	193	1 431	43	28,7	318	28,6
Alt-Hohenschönhausen Süd.....	334	1 137	316	1 073	- 18	- 5,4	- 64	- 5,6
Fennpfuhl.....	419	1 321	318	993	- 101	- 24,1	- 328	- 24,8
Alt-Lichtenberg.....	377	1 570	388	1 556	11	2,9	- 14	- 0,9
Frankfurter Allee Süd.....	105	1 087	104	1 038	- 1	- 1,0	- 49	- 4,5
Neu-Lichtenberg.....	428	1 457	318	1 058	- 110	- 25,7	- 399	- 27,4
Friedrichsfelde Nord.....	202	1 516	142	1 050	- 60	- 29,7	- 466	- 30,7
Friedrichsfelde Süd.....	225	933	202	822	- 23	- 10,2	- 111	- 11,9
Rummelsburger Bucht.....	67	2 053	63	1 900	- 4	x	- 153	(- 7,5)
Karlshorst.....	180	797	192	824	12	6,7	27	3,4
nicht zuzuordnen.....	248		169					

Bezirk Berlin Reinickendorf

Sachbeschädigung -insgesamt (Häufigkeitszahl)

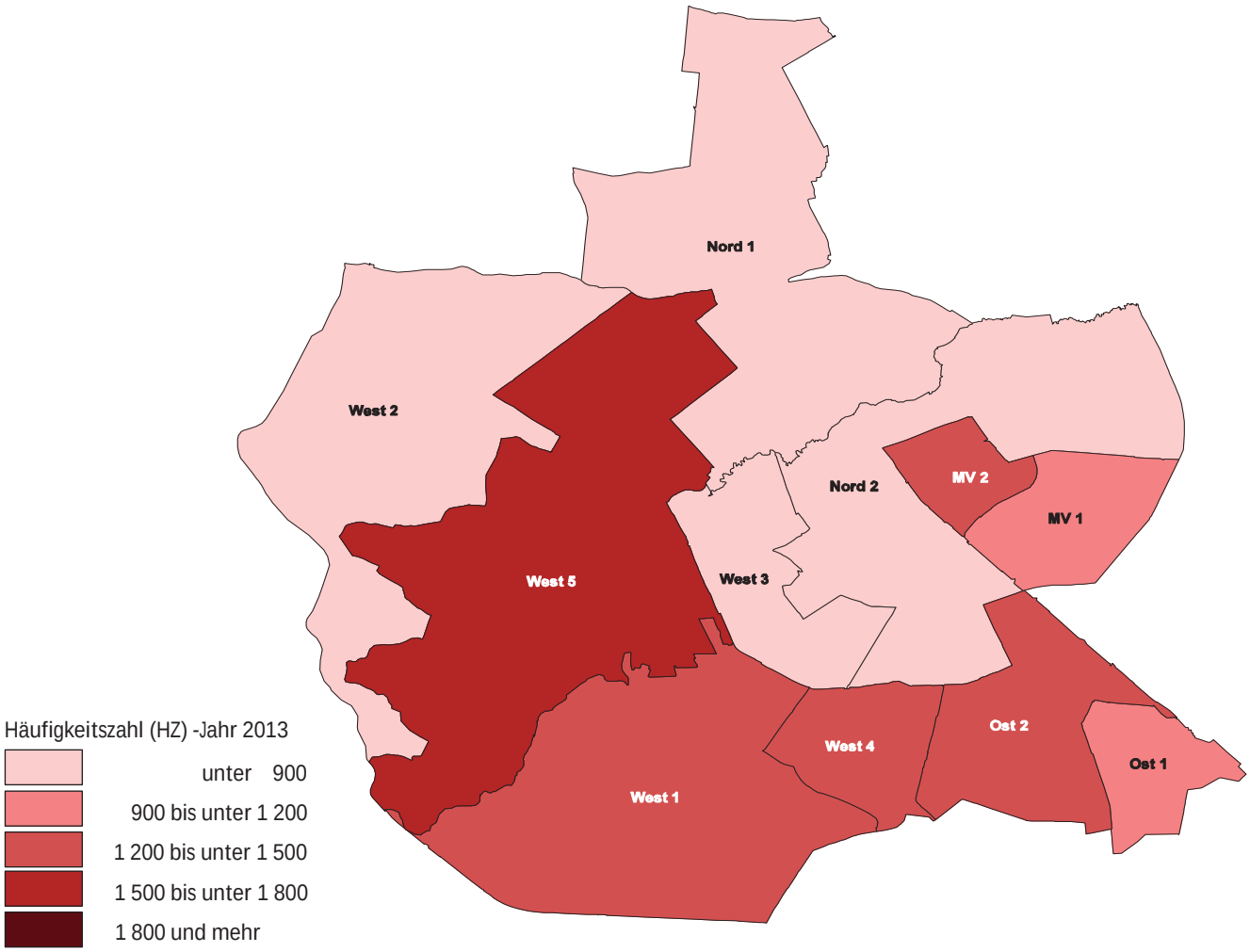

Sachbeschädigung -insgesamt- (PKS-Schlüssel 674000)

Bezirksregion	Jahr 2012		Jahr 2013		Zu-/Abnahme			
	erfasste Fälle	HZ	erfasste Fälle	HZ	Fälle		HZ	
					absolut	in %	absolut	in %
Ost 1	337	1 314	260	1 001	- 77	- 22,8	- 313	- 23,8
Ost 2	324	1 270	322	1 245	- 2	- 0,6	- 25	- 2,0
West 1	285	1 959	175	1 210	- 110	- 38,6	- 749	- 38,2
West 4	328	1 312	321	1 263	- 7	- 2,1	- 49	- 3,7
West 5	219	2 144	165	1 603	- 54	- 24,7	- 541	- 25,2
West 2	299	1 269	212	892	- 87	- 29,1	- 377	- 29,7
Nord 1	250	765	227	692	- 23	- 9,2	- 73	- 9,5
Nord 2	356	1 220	264	887	- 92	- 25,8	- 333	- 27,3
MV 1	505	1 426	428	1 177	- 77	- 15,2	- 249	- 17,5
MV 2	101	1 233	116	1 364	15	14,9	131	10,6
West 3	167	1 045	117	732	- 50	- 29,9	- 313	- 30,0
nicht zuzuordnen	124		92					

Berlin - Sachbeschädigung durch Graffiti (Häufigkeitszahl)

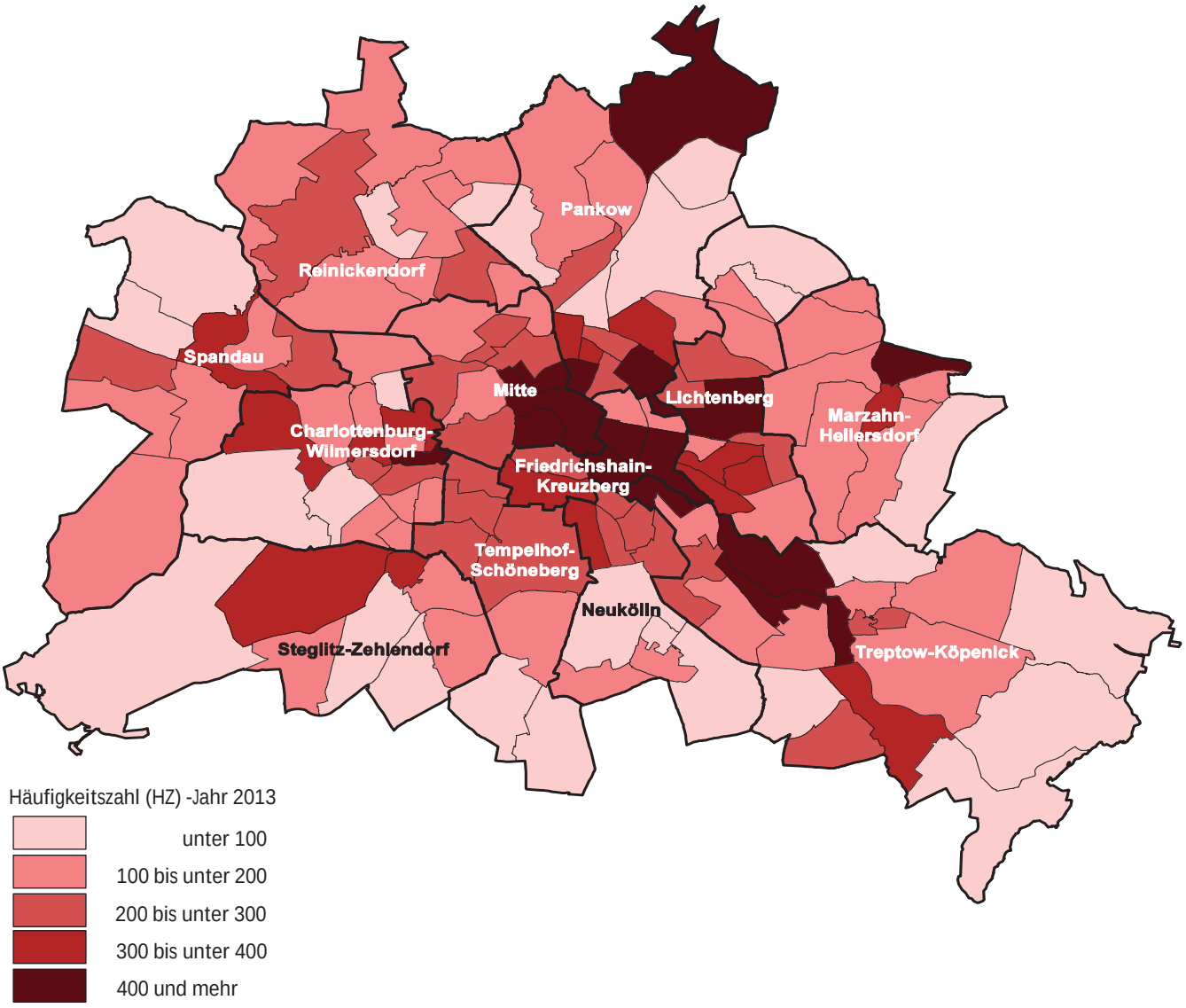

Sachbeschädigung durch Graffiti (PKS-Schlüssel 674**1)

Bezirk	Jahr 2012		Jahr 2013		Zu-/Abnahme			
	erfasste Fälle	HZ	erfasste Fälle	HZ	Fälle absolut	Fälle in %	HZ absolut	HZ in %
Mitte	1 346	401	1 392	405	46	3,4	4	1,0
Friedrichshain-Kreuzberg	1 311	491	1 168	431	- 143	- 10,9	- 60	- 12,2
Pankow	1 294	352	1 075	288	- 219	- 16,9	- 64	- 18,2
Charlottenburg-Wilmersdorf	847	267	889	277	42	5,0	10	3,7
Spandau	542	245	481	214	- 61	- 11,3	- 31	- 12,7
Steglitz-Zehlendorf	772	262	643	217	- 129	- 16,7	- 45	- 17,2
Tempelhof-Schöneberg	822	251	673	204	- 149	- 18,1	- 47	- 18,7
Neukölln	789	250	660	206	- 129	- 16,3	- 44	- 17,6
Treptow-Köpenick	1 016	419	827	338	- 189	- 18,6	- 81	- 19,3
Marzahn-Hellersdorf	800	320	620	245	- 180	- 22,5	- 75	- 23,4
Lichtenberg	896	347	711	271	- 185	- 20,6	- 76	- 21,9
Reinickendorf	635	258	434	174	- 201	- 31,7	- 84	- 32,6
Berlin, nicht zuzuordnen	505		86					
Berlin -Gesamt-	**11 575**	**343**	**9 659**	**284**	**- 1 916**	**-16,6**	**- 60**	**-17,4**

Bezirk Berlin Mitte

Sachbeschädigung durch Graffiti (Häufigkeitszahl)

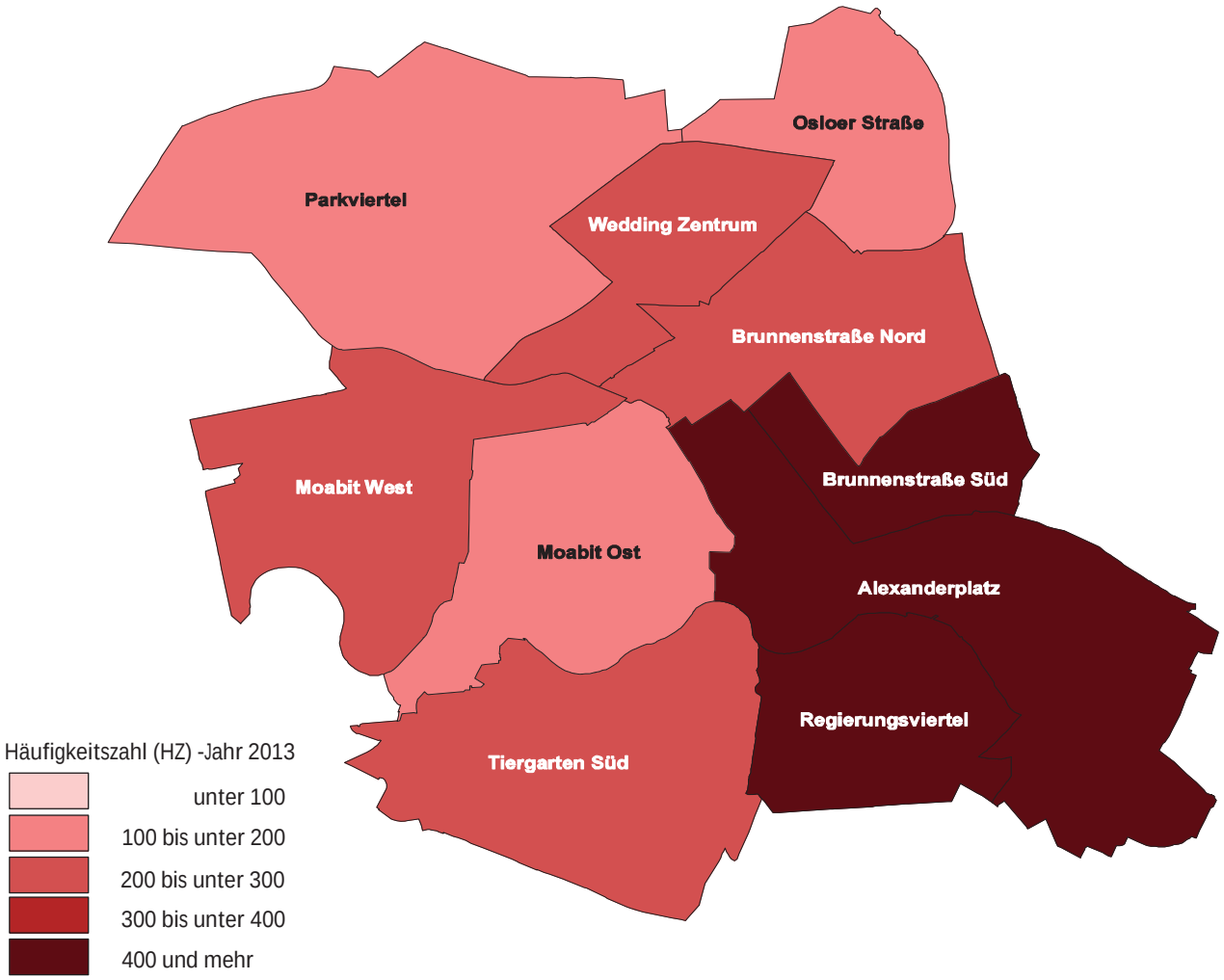

Sachbeschädigung durch Graffiti (PKS-Schlüssel 674**1)

Bezirksregion	Jahr 2012		Jahr 2013		Zu-/Abnahme			
	erfasste Fälle	HZ	erfasste Fälle	HZ	Fälle absolut	Fälle in %	HZ absolut	HZ in %
Tiergarten Süd	26	206	28	215	2	x	9	(4,4)
Regierungsviertel	124	1 353	130	1 398	6	4,8	45	3,3
Alexanderplatz	522	1 106	448	931	- 74	- 14,2	- 175	- 15,8
Brunnenstraße Süd	122	477	134	505	12	9,8	28	5,9
Moabit West	64	153	88	206	24	x	53	(34,6)
Moabit Ost	52	149	59	167	7	x	18	(12,1)
Osloer Straße	72	205	55	152	- 17	x	- 53	(-25,9)
Brunnenstraße Nord	72	204	84	234	12	x	30	(14,7)
Parkviertel	65	157	81	191	16	x	34	(21,7)
Wedding Zentrum	87	166	127	235	40	x	69	(41,6)
nicht zuzuordnen	140	-	158	-				

Bezirk Berlin Friedrichshain-Kreuzberg

Sachbeschädigung durch Graffiti (Häufigkeitszahl)

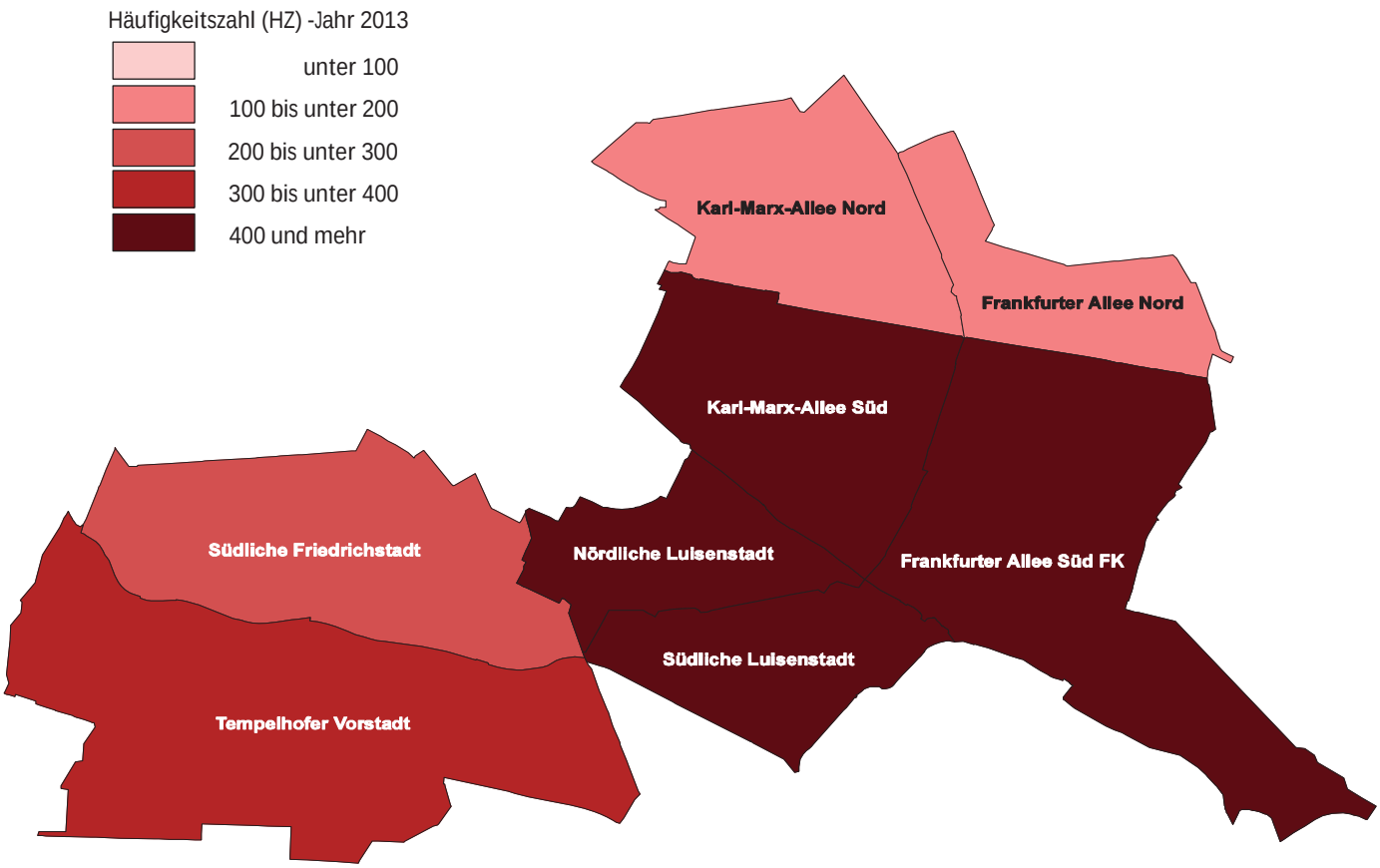

Sachbeschädigung durch Graffiti (PKS-Schlüssel 674**1)

Bezirksregion	Jahr 2012		Jahr 2013		Zu-/Abnahme			
	erfasste Fälle	HZ	erfasste Fälle	HZ	Fälle		HZ	
					absolut	in %	absolut	in %
Südliche Friedrichstadt.....	102	262	84	213	- 18	- 17,6	- 49	- 18,7
Tempelhofer Vorstadt.....	194	318	187	302	- 7	- 3,6	- 16	- 5,0
Nördliche Luisenstadt.....	82	367	120	532	38	x	165	(45,0)
Südliche Luisenstadt.....	129	494	137	518	8	6,2	24	4,9
Karl-Marx-Allee Nord.....	46	207	27	120	- 19	x	- 87	(- 42,0)
Karl-Marx-Allee Süd.....	87	379	117	500	30	x	121	(31,9)
Frankfurter Allee Nord.....	84	309	55	199	- 29	x	- 110	(- 35,6)
Frankfurter Allee Süd FK.....	272	589	308	652	36	13,2	63	10,7
nicht zuzuordnen.....	315		133					

Bezirk Berlin Pankow

Sachbeschädigung durch Graffiti (Häufigkeitszahl)

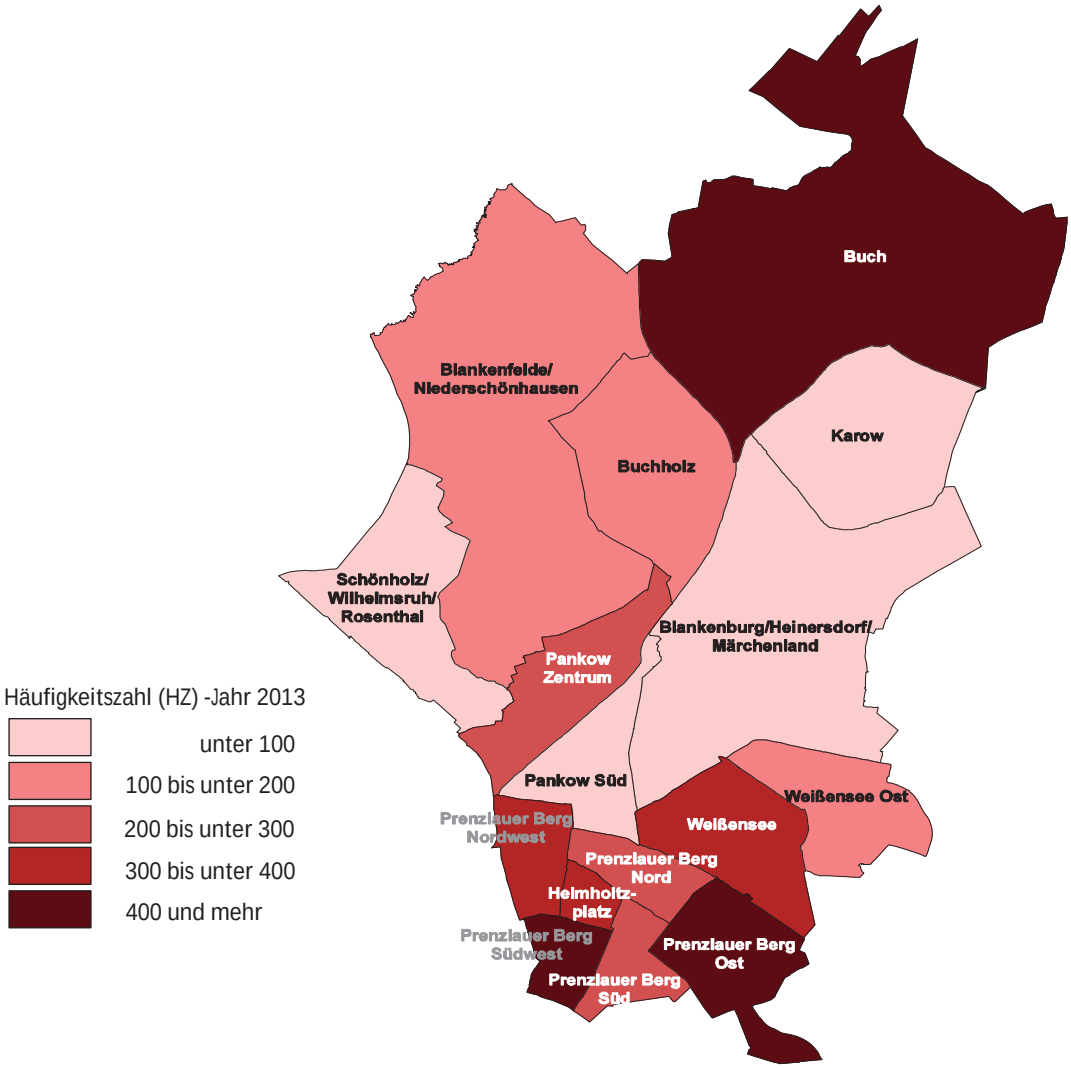

Sachbeschädigung durch Graffiti (PKS-Schlüssel 674**1)

Bezirksregion	Jahr 2012		Jahr 2013		Zu-/Abnahme			
	erfasste Fälle	HZ	erfasste Fälle	HZ	Fälle absolut	Fälle in %	HZ absolut	HZ in %
Buch	35	268	55	406	20	x	138	(51,5)
Blankenfelde/Niederschönhausen	31	122	34	131	3	x	9	(7,4)
Buchholz	7	42	23	135	16	x	93	x
Karow	24	128	11	59	- 13	x	- 69	(- 53,9)
Blankenburg/Heinersdorf	9	64	7	50	- 2	x	- 14	x
Pankow Süd	78	245	25	77	- 53	x	- 168	(- 68,6)
Schönholz/Wilhelmsruh/Rosenthal	19	111	16	93	- 3	x	- 18	(- 16,2)
Pankow Zentrum	101	311	71	213	- 30	- 29,7	- 98	- 31,5
Weißensee	152	461	102	303	- 50	- 32,9	- 158	- 34,3
Weißensee Ost	32	213	18	119	- 14	x	- 94	(- 44,1)
Prenzlauer Berg Nordwest	113	478	78	322	- 35	- 31,0	- 156	- 32,6
Prenzlauer Berg Nord	75	291	61	234	- 14	x	- 57	(- 19,6)
Helmholtzplatz	100	472	65	300	- 35	- 35,0	- 172	- 36,4
Prenzlauer Berg Ost	131	539	167	673	36	27,5	134	24,9
Prenzlauer Berg Südwest	192	792	130	524	- 62	- 32,3	- 268	- 33,8
Prenzlauer Berg Süd	84	273	70	225	- 14	x	- 48	(- 17,6)
nicht zuzuordnen	111		142					

Bezirk Berlin Charlottenburg-Wilmersdorf

Sachbeschädigung durch Graffiti (Häufigkeitszahl)

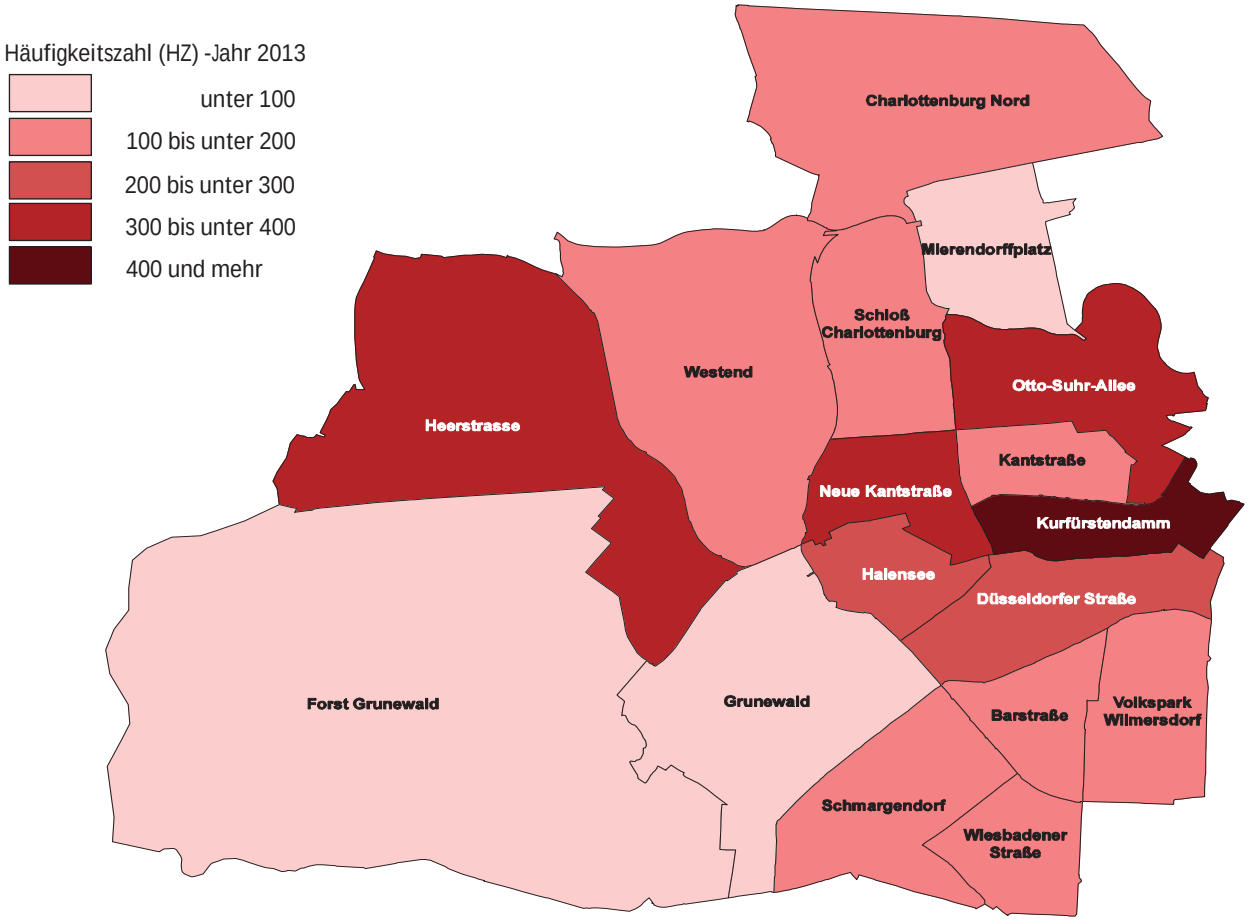

Sachbeschädigung durch Graffiti (PKS-Schlüssel 674**1)

Bezirksregion	Jahr 2012		Jahr 2013		Zu-/Abnahme			
	erfasste Fälle	HZ	erfasste Fälle	HZ	Fälle absolut	Fälle in %	HZ absolut	HZ in %
Charlottenburg Nord.....	5	28	20	108	15	x	80	x
Heerstraße.....	36	288	47	373	11	x	85	(29,5)
Westend.....	36	138	34	128	- 2	x	- 10	(- 7,2)
Schloß Charlottenburg.....	23	99	28	120	5	x	21	x
Mierendorffplatz.....	18	127	13	89	- 5	x	- 38	(- 29,9)
Otto-Suhr-Allee.....	95	373	94	365	- 1	x	- 8	(- 2,1)
Neue Kantstraße.....	20	87	73	315	53	x	228	x
Kantstraße.....	22	108	25	121	3	x	13	(12,0)
Kurfürstendamm.....	95	652	75	514	- 20	x	- 138	(- 21,2)
Halensee.....	23	162	38	263	15	x	101	(62,3)
Grunewald.....	14	78	14	77		x	- 1	x
Schmargendorf.....	12	87	17	122	5	x	35	x
Wiesbadener Straße.....	21	116	25	138	4	x	22	(19,0)
Düsseldorfer Straße.....	113	385	89	299	- 24	- 21,2	- 86	- 22,3
Barstraße.....	29	215	21	155	- 8	x	- 60	(- 27,9)
Volkspark Wilmersdorf.....	66	204	61	186	- 5	x	- 18	(- 8,8)
Forst Grunewald.....	1				- 1	x		
nicht zuzuordnen.....	218		215					

Bezirk Berlin Spandau

Sachbeschädigung durch Graffiti (Häufigkeitszahl)

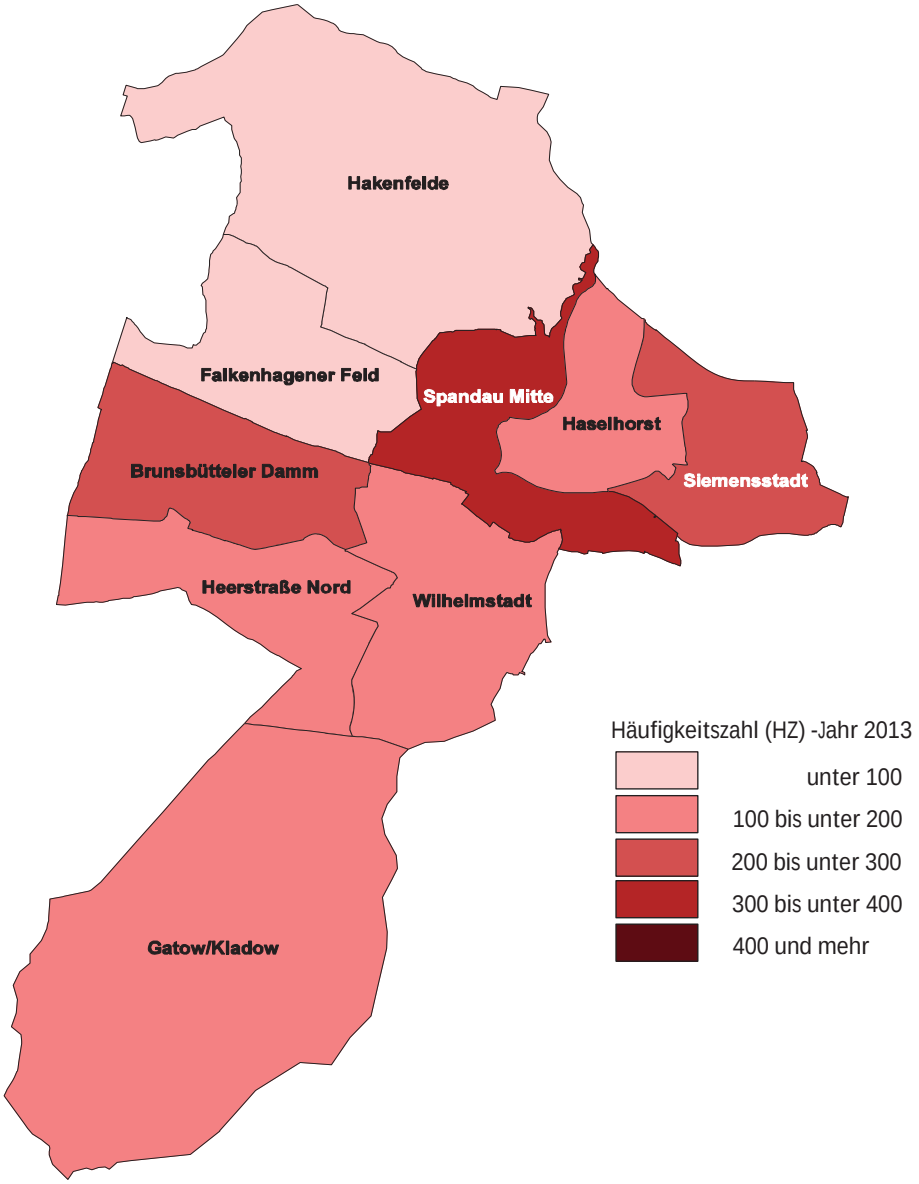

Sachbeschädigung durch Graffiti (PKS-Schlüssel 674**1)

Bezirksregion	Jahr 2012		Jahr 2013		Zu-/Abnahme			
	erfasste Fälle	HZ	erfasste Fälle	HZ	Fälle		HZ	
					absolut	in %	absolut	in %
Hakenfelde.....	15	66	21	92	6	x	26	x
Falkenhagener Feld.....	46	118	13	33	- 33	x	- 85	(- 72,0)
Spandau Mitte.....	103	313	112	332	9	8,7	19	6,1
Brunsbütteler Damm.....	21	91	56	242	35	x	151	x
Heerstraße Nord.....	34	127	43	161	9	x	34	(26,8)
Wilhelmstadt.....	85	251	39	113	- 46	x	- 138	(- 55,0)
Haselhorst.....	21	153	22	152	1	x	- 1	(- 0,7)
Siemensstadt.....	30	258	28	234	- 2	x	- 24	(- 9,3)
Gatow/Kladow.....	20	113	28	154	8	x	41	(36,3)
nicht zuzuordnen.....	167		119					

Bezirk Berlin Steglitz-Zehlendorf

Sachbeschädigung durch Graffiti (Häufigkeitszahl)

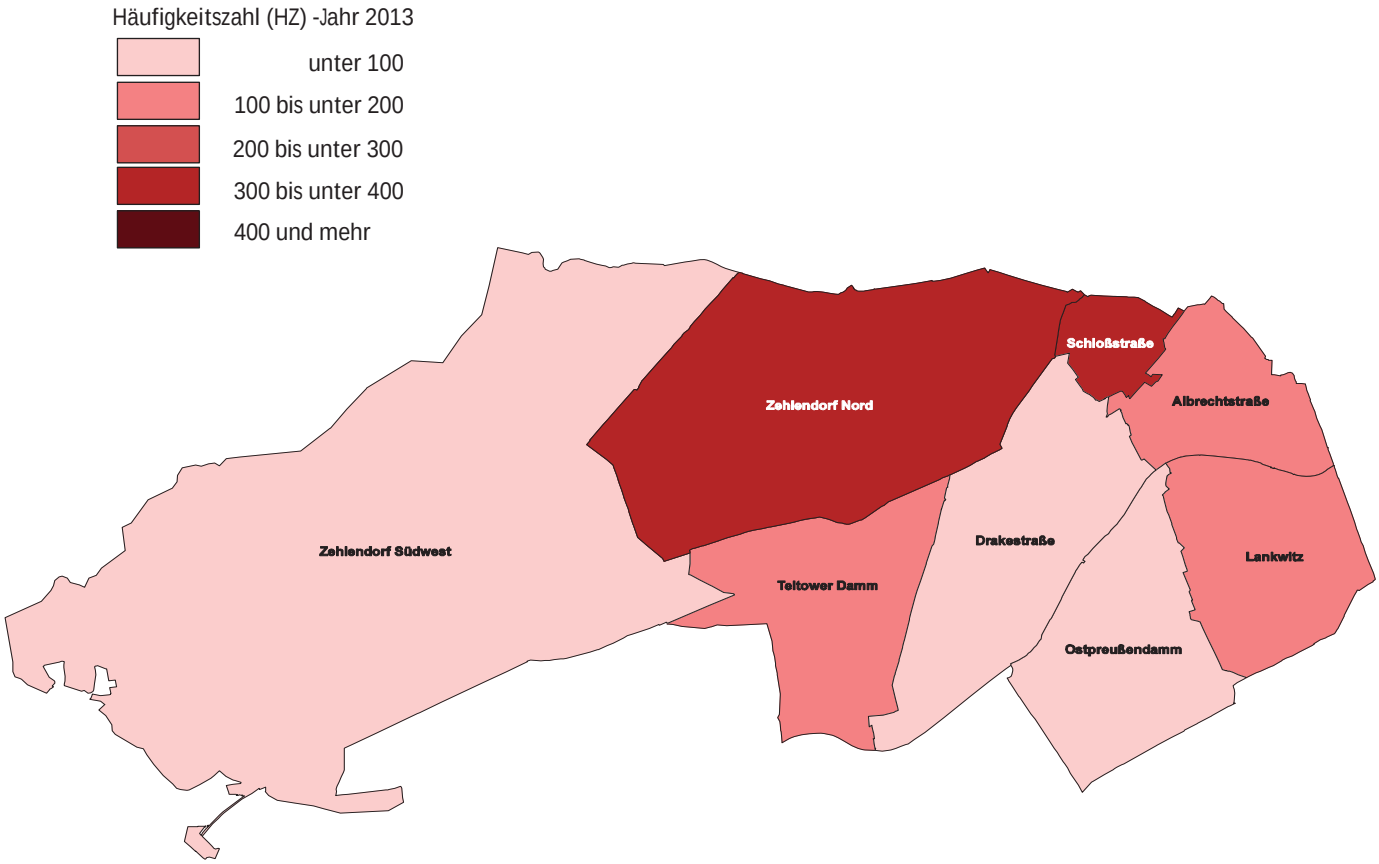

Sachbeschädigung durch Graffiti (PKS-Schlüssel 674**1)

Bezirksregion	Jahr 2012		Jahr 2013		Zu-/Abnahme			
	erfasste Fälle	HZ	erfasste Fälle	HZ	Fälle absolut	Fälle in %	HZ absolut	HZ in %
Schloßstraße	57	266	75	347	18	x	81	(30,5)
Albrechtstraße	111	216	62	120	- 49	- 44,1	- 96	- 44,4
Lankwitz	75	181	70	168	- 5	x	- 13	(- 7,2)
Ostpreußendamm	37	107	34	97	- 3	x	- 10	(- 9,3)
Teltower Damm	70	214	39	119	- 31	x	- 95	(- 44,4)
Drakestraße	61	133	33	71	- 28	x	- 62	(- 46,6)
Zehlendorf Südwest	26	102	22	86	- 4	x	- 16	(- 15,7)
Zehlendorf Nord	164	395	139	335	- 25	- 15,2	- 60	- 15,2
nicht zuzuordnen	171		169					

Bezirk Berlin Tempelhof-Schöneberg

Sachbeschädigung durch Graffiti (Häufigkeitszahl)

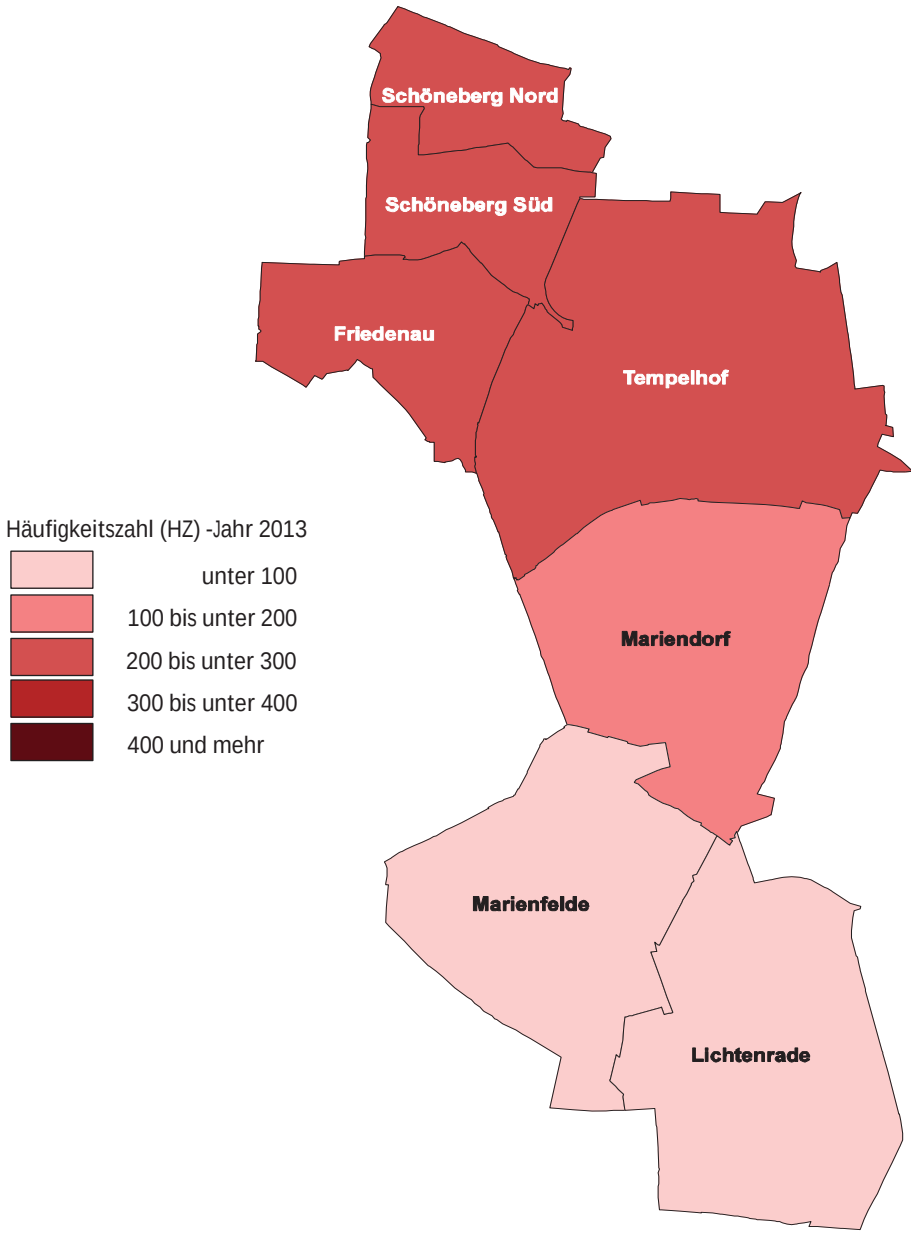

Sachbeschädigung durch Graffiti (PKS-Schlüssel 674**1)

Bezirksregion	Jahr 2012		Jahr 2013		Zu-/Abnahme			
	erfasste Fälle	HZ	erfasste Fälle	HZ	Fälle absolut	Fälle in %	HZ absolut	HZ in %
Schöneberg Nord	157	333	135	288	- 22	- 14,0	- 45	- 13,5
Schöneberg Süd	145	305	113	237	- 32	- 22,1	- 68	- 22,3
Friedenau	107	243	106	239	- 1	- 0,9	- 4	- 1,6
Tempelhof	129	219	123	205	- 6	- 4,7	- 14	- 6,4
Mariendorf	75	151	59	118	- 16	x	- 33	(- 21,9)
Marienfelde	34	112	23	75	- 11	x	- 37	(- 33,0)
Lichtenrade	70	142	46	93	- 24	x	- 49	(- 34,5)
nicht zuzuordnen	105		68					

Bezirk Berlin Neukölln

Sachbeschädigung durch Graffiti (Häufigkeitszahl)

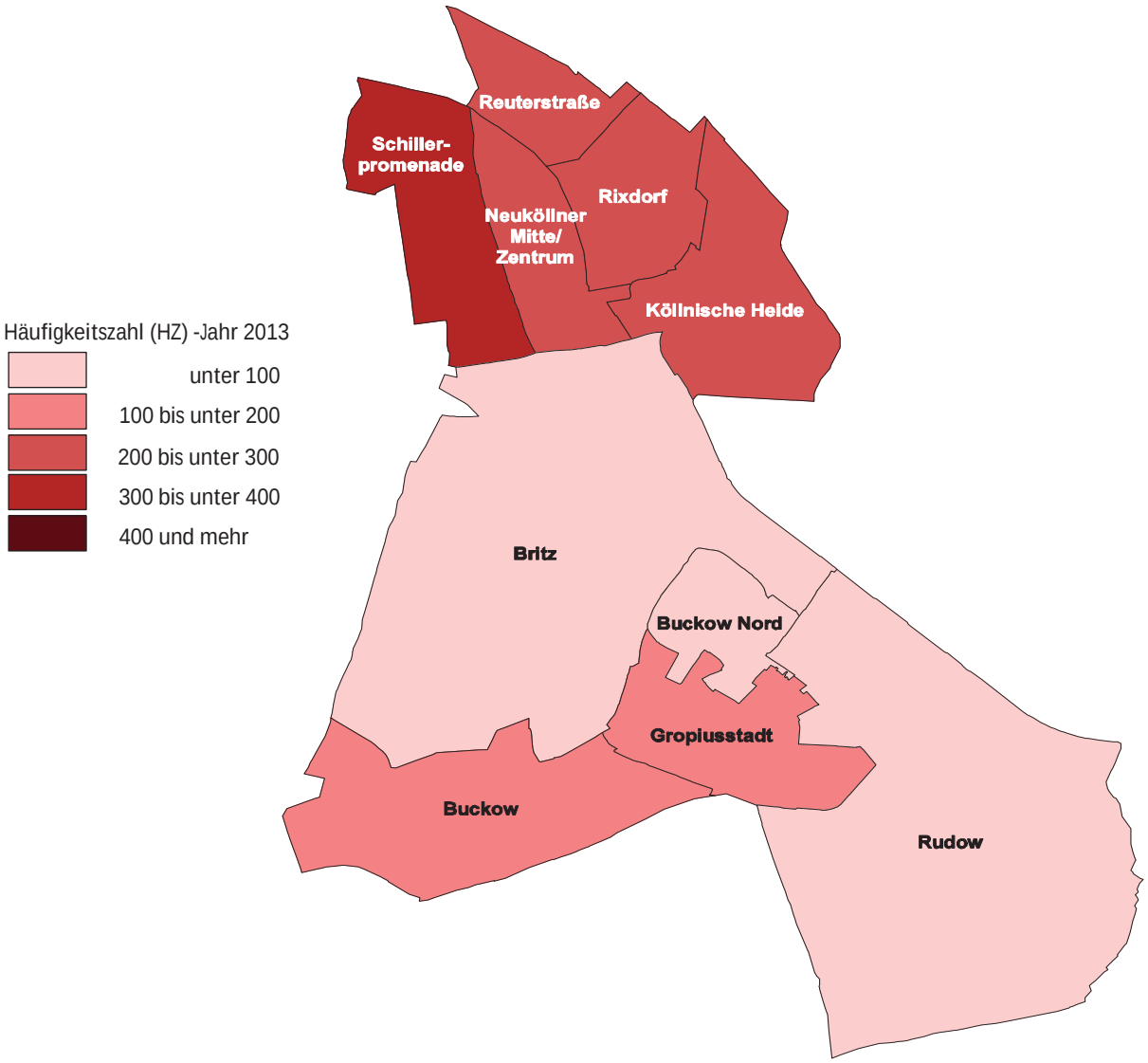

Sachbeschädigung durch Graffiti (PKS-Schlüssel 674**1)

Bezirksregion	Jahr 2012		Jahr 2013		Zu-/Abnahme			
	erfasste Fälle	HZ	erfasste Fälle	HZ	Fälle absolut	Fälle in %	HZ absolut	HZ in %
Schillerpromenade	85	275	119	377	34	x	102	(37,1)
Neuköllner Mitte/Zentrum	157	426	109	289	- 48	- 30,6	- 137	- 32,2
Reuterstraße	97	250	112	282	15	x	32	(12,8)
Rixdorf	80	206	86	218	6	x	12	(5,8)
Köllnische Heide	61	414	45	299	- 16	x	- 115	(- 27,8)
Britz	63	156	39	95	- 24	x	- 61	(- 39,1)
Buckow	63	228	29	104	- 34	x	- 124	(- 54,4)
Gropiusstadt	79	219	54	149	- 25	x	- 70	(- 32,0)
Buckow Nord	3	32	5	53	2	x	21	x
Rudow	65	155	23	55	- 42	x	- 100	(- 64,5)
nicht zuzuordnen	36		39					

Bezirk Berlin Treptow-Köpenick

Sachbeschädigung durch Graffiti (Häufigkeitszahl)

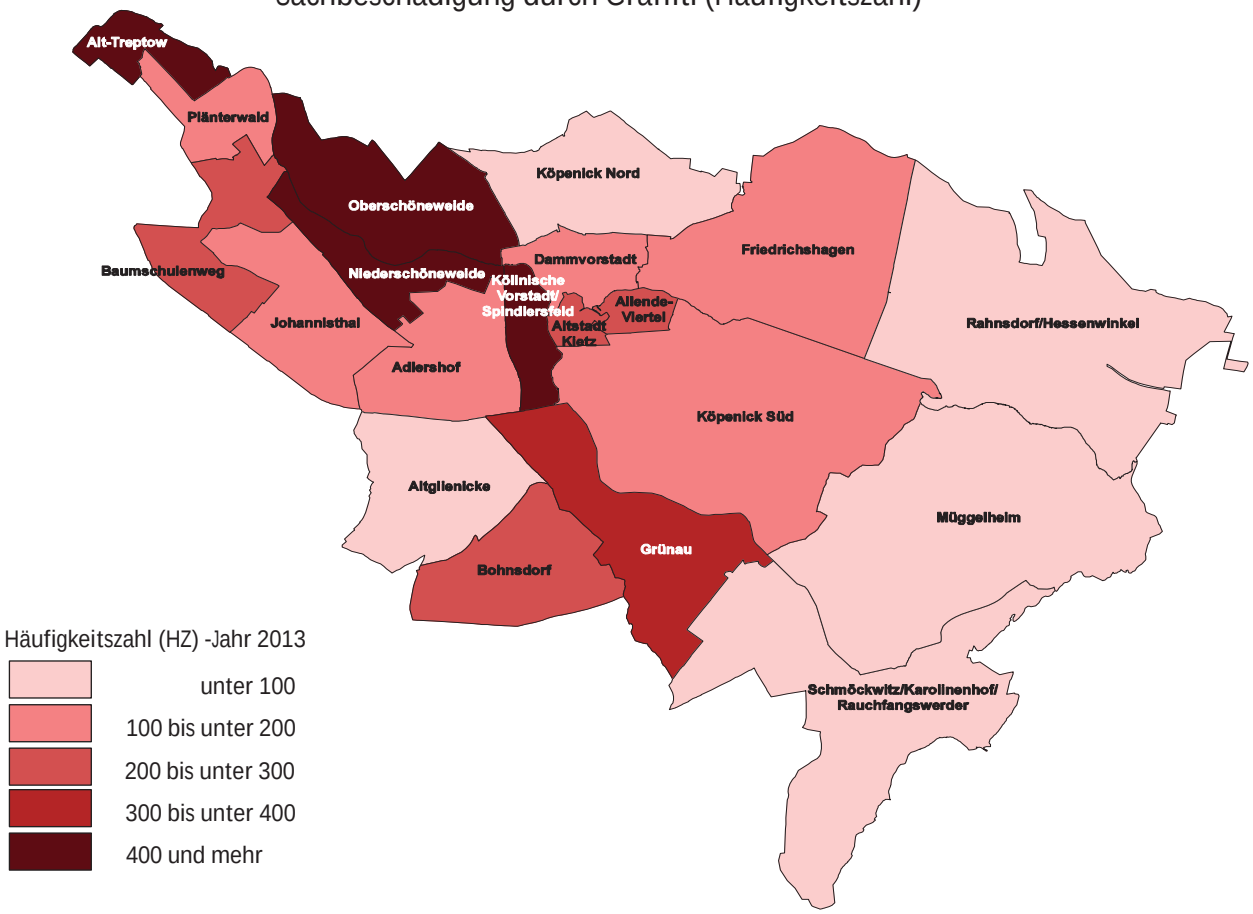

Sachbeschädigung durch Graffiti (PKS-Schlüssel 674**1)

Bezirksregion	Jahr 2012		Jahr 2013		Zu-/Abnahme			
	erfasste Fälle	HZ	erfasste Fälle	HZ	Fälle absolut	Fälle in %	HZ absolut	HZ in %
Alt-Treptow	69	632	51	460	- 18	x	- 172	(- 27,2)
Plänterwald	37	343	16	148	- 21	x	- 195	(- 56,9)
Baumschulenweg	82	476	46	264	- 36	x	- 212	(- 44,5)
Johannisthal	59	322	34	184	- 25	x	- 138	(- 42,9)
Oberschöneweide	58	303	132	669	74	x	366	(120,8)
Niederschöneweide	65	622	51	480	- 14	x	- 142	(- 22,8)
Adlershof	53	344	28	179	- 25	x	- 165	(- 48,0)
Kölln. Vorstadt/Spindlersf.	56	569	64	640	8	x	71	(12,5)
Altglienicke	36	141	19	73	- 17	x	- 68	(- 48,2)
Bohnsdorf	24	202	34	282	10	x	80	(39,6)
Grünau	32	593	18	321	- 14	x	- 272	(- 45,9)
Schmöckwitz/Karolinenhof	9	222	2	50	- 7	x	- 172	(- 77,5)
Köpenick Süd	10	64	28	180	18	x	116	x
Allende-Viertel	15	246	16	261	1	x	15	(6,1)
Altstadt Kietz	37	539	16	231	- 21	x	- 308	(- 57,1)
Müggelheim	2	31		-	- 2	x	- 31	x
Friedrichshagen	29	166	25	143	- 4	x	- 23	(- 13,9)
Rahnsdorf/Hessenwinkel	3	33	5	56	2	x	23	x
Dammvorstadt	33	350	12	126	- 21	x	- 224	(- 64,0)
Köpenick Nord	14	114	9	73	- 5	x	- 41	(- 36,0)
nicht zuzuordnen	293		221					

Bezirk Berlin Marzahn-Hellersdorf

Sachbeschädigung durch Graffiti (Häufigkeitszahl)

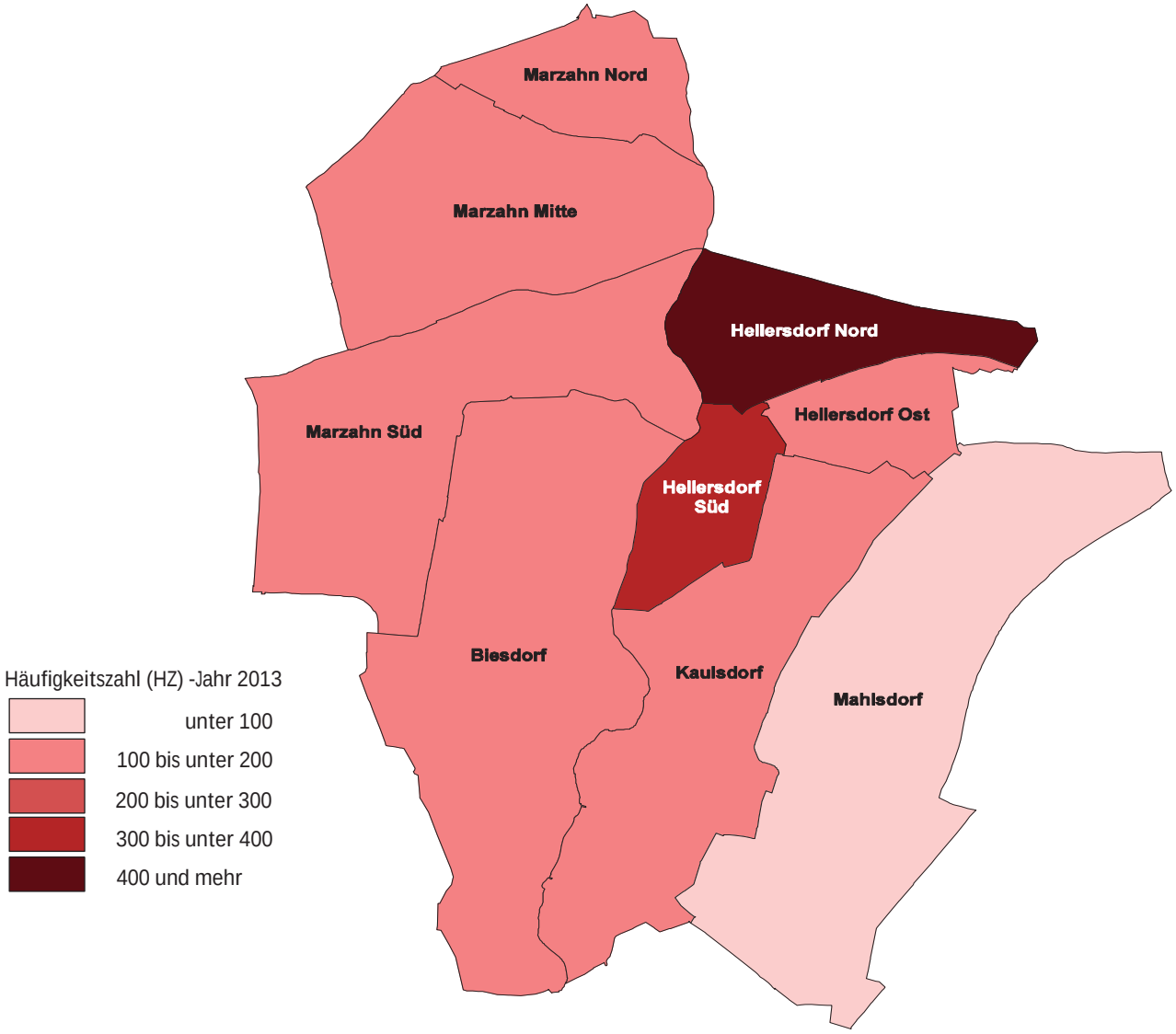

Sachbeschädigung durch Graffiti (PKS-Schlüssel 674**1)

Bezirksregion	Jahr 2012		Jahr 2013		Zu-/Abnahme			
	erfasste Fälle	HZ	erfasste Fälle	HZ	Fälle absolut	Fälle in %	HZ absolut	HZ in %
Marzahn Nord	55	243	43	188	- 12	x	- 55	(- 22,6)
Marzahn Mitte	59	131	68	149	9	x	18	(13,7)
Marzahn Süd	81	224	66	180	- 15	x	- 44	(- 19,6)
Hellersdorf Nord	173	528	150	450	- 23	- 13,3	- 78	- 14,8
Hellersdorf Ost	86	466	33	175	- 53	x	- 291	(- 62,4)
Hellersdorf Süd	97	400	75	307	- 22	x	- 93	(- 23,3)
Biesdorf	45	179	28	110	- 17	x	- 69	(- 38,5)
Kaulsdorf	27	144	26	139	- 1	x	- 5	(- 3,5)
Mahlsdorf	87	322	25	92	- 62	x	- 230	(- 71,4)
nicht zuzuordnen	90		106					

Bezirk Berlin Lichtenberg

Sachbeschädigung durch Graffiti (Häufigkeitszahl)

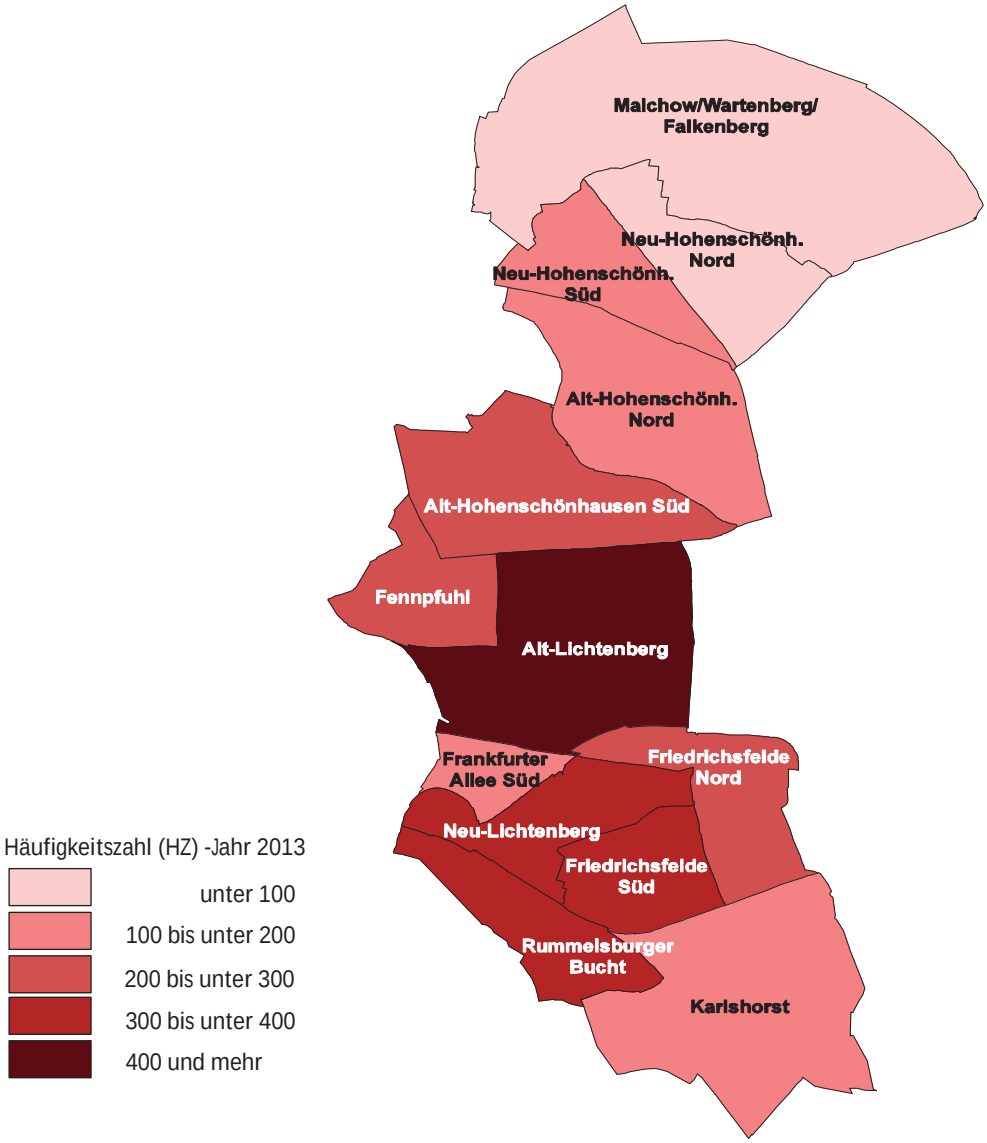

Sachbeschädigung durch Graffiti (PKS-Schlüssel 674**1)

Bezirksregion	Jahr 2012		Jahr 2013		Zu-/Abnahme			
	erfasste Fälle	HZ	erfasste Fälle	HZ	Fälle absolut	Fälle in %	HZ absolut	HZ in %
Malchow/Warten-/Falkenberg.....	13	310	3	71	- 10	x	- 239	(- 77,1)
Neu-Hohenschönhausen Nord.....	56	204	27	98	- 29	x	- 106	(- 52,0)
Neu-Hohenschönhausen Süd.....	35	135	30	116	- 5	x	- 19	(- 14,1)
Alt-Hohenschönhausen Nord.....	30	223	26	193	- 4	x	- 30	(- 13,5)
Alt-Hohenschönhausen Süd.....	72	245	71	241	- 1	x	- 4	(- 1,6)
Fennpfuhl.....	90	284	72	225	- 18	x	- 59	(- 20,8)
Alt-Lichtenberg.....	75	312	103	413	28	x	101	(32,4)
Frankfurter Allee Süd.....	12	124	13	130	1	x	6	(4,8)
Neu-Lichtenberg.....	128	436	94	313	- 34	- 26,6	- 123	- 28,2
Friedrichsfelde Nord.....	64	480	28	207	- 36	x	- 273	(- 56,9)
Friedrichsfelde Süd.....	61	253	76	309	15	x	56	(22,1)
Rummelsburger Bucht.....	20	613	13	392	- 7	x	- 221	(- 36,1)
Karlshorst.....	60	266	32	137	- 28	x	- 129	(- 48,5)
nicht zuzuordnen.....	180		123					

Bezirk Berlin Reinickendorf

Sachbeschädigung durch Graffiti (Häufigkeitszahl)

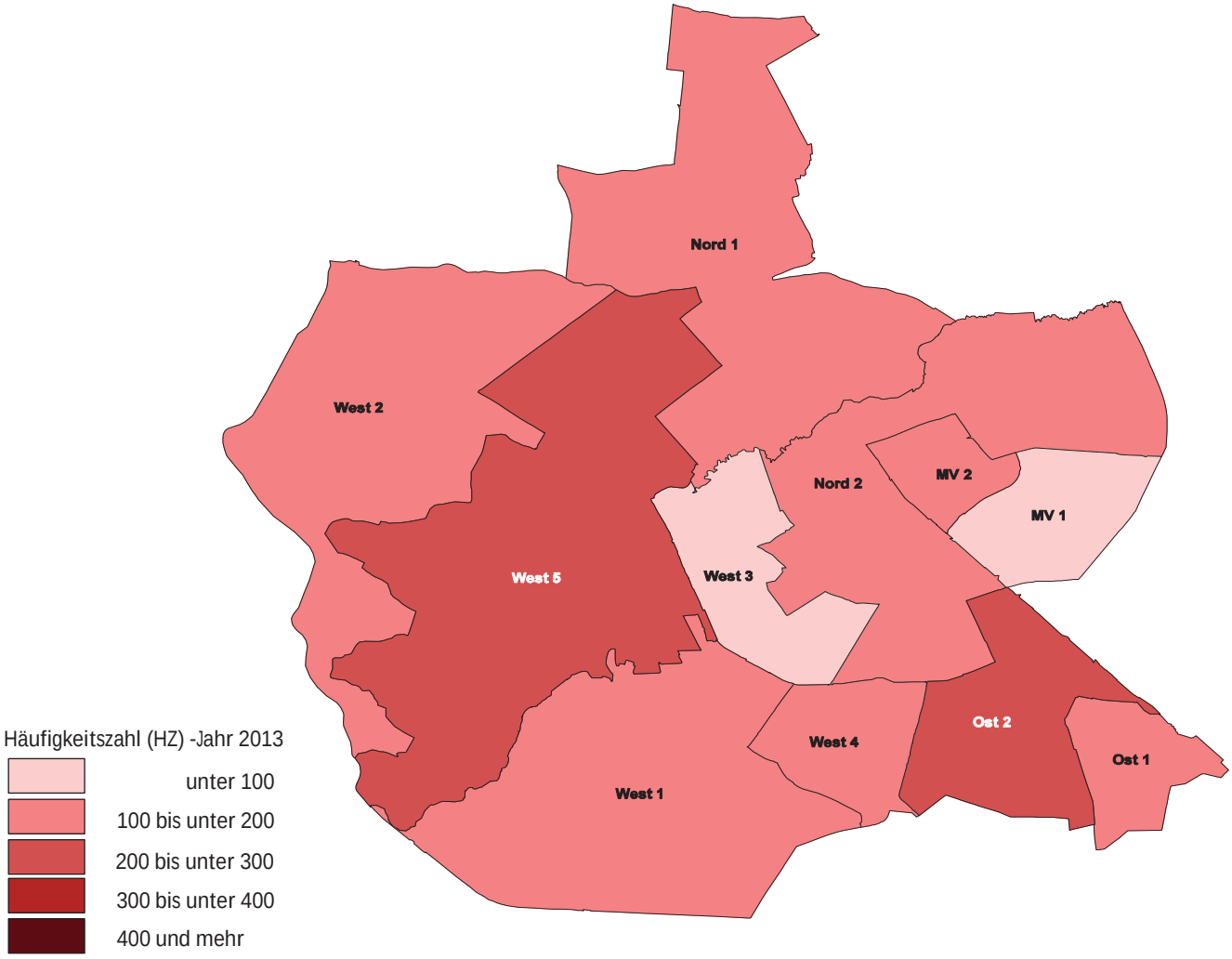

Sachbeschädigung durch Graffiti (PKS-Schlüssel 674**1)

Bezirksregion	Jahr 2012		Jahr 2013		Zu-/Abnahme			
	erfasste Fälle	HZ	erfasste Fälle	HZ	Fälle absolut	Fälle in %	HZ absolut	HZ in %
Ost 1	34	133	29	112	- 5	x	- 21	(- 15,8)
Ost 2	53	208	55	213	2	x	5	(2,4)
West 1	27	186	23	159	- 4	x	- 27	(- 14,5)
West 4	47	188	43	169	- 4	x	- 19	(- 10,1)
West 5	47	460	30	291	- 17	x	- 169	(- 36,7)
West 2	114	484	36	151	- 78	- 68,4	- 333	- 68,8
Nord 1	57	174	49	149	- 8	x	- 25	(- 14,4)
Nord 2	81	277	59	198	- 22	x	- 79	(- 28,5)
MV 1	72	203	36	99	- 36	x	- 104	(- 51,2)
MV 2	10	122	15	176	5	x	54	(44,3)
West 3	20	125	13	81	- 7	x	- 44	(- 35,2)
nicht zuzuordnen	73		46					

Berlin - Rauschgiftdelikte (Häufigkeitszahl)

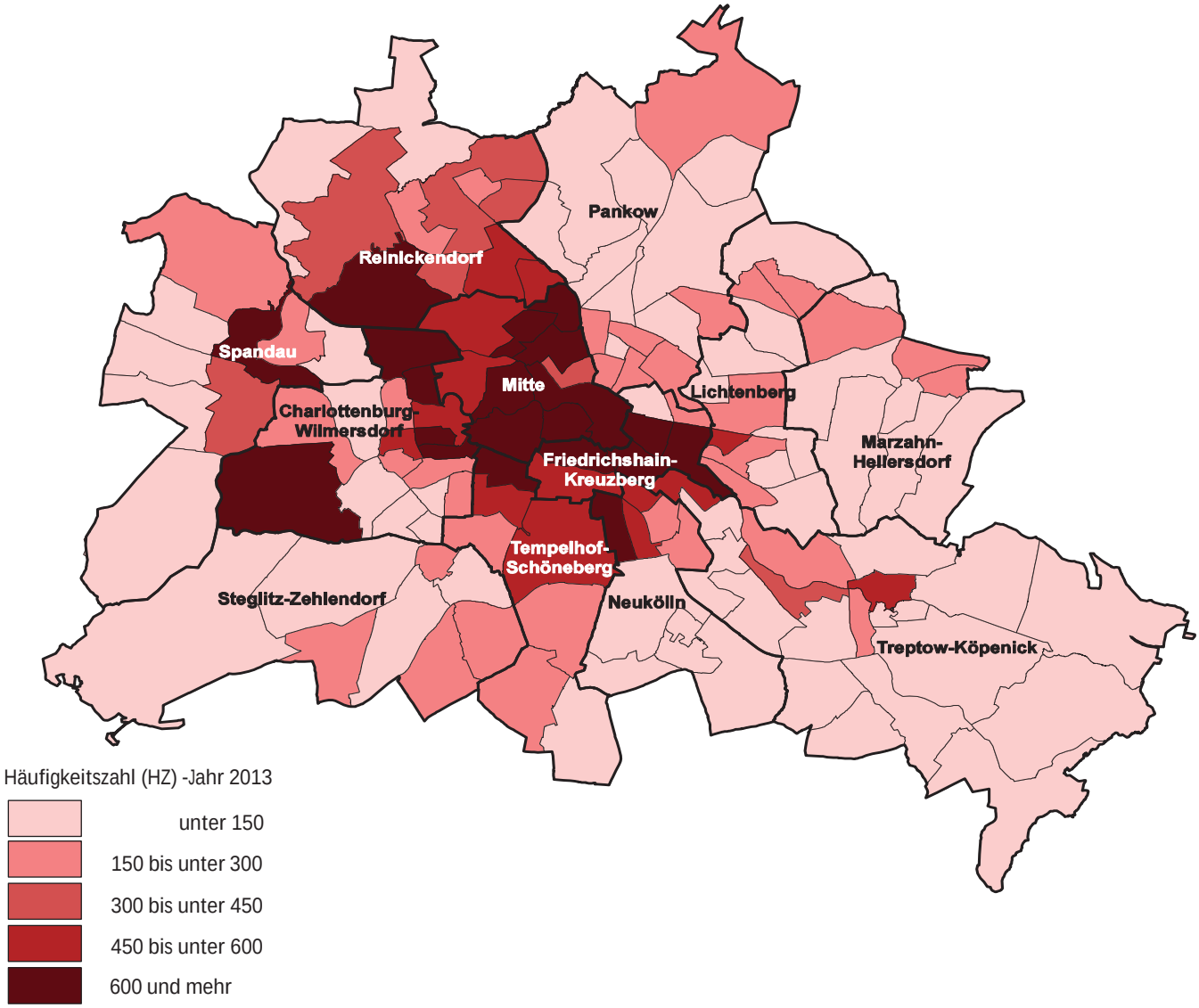

Rauschgiftdelikte (PKS-Schlüssel 730000)

Bezirk	Jahr 2012		Jahr 2013		Zu-/Abnahme			
	erfasste Fälle	HZ	erfasste Fälle	HZ	Fälle absolut	Fälle in %	HZ absolut	HZ in %
Mitte	2 849	849	2 864	834	15	0,5	- 15	- 1,8
Friedrichshain-Kreuzberg	1 853	694	2 391	882	538	29,0	188	27,1
Pankow	522	142	539	144	17	3,3	2	1,4
Charlottenburg-Wilmersdorf	1 064	336	1 180	368	116	10,9	32	9,5
Spandau	481	217	528	235	47	9,8	18	8,3
Steglitz-Zehlendorf	298	101	423	143	125	41,9	42	41,6
Tempelhof-Schöneberg	1 066	326	1 122	341	56	5,3	15	4,6
Neukölln	1 578	500	1 635	510	57	3,6	10	2,0
Treptow-Köpenick	309	128	342	140	33	10,7	12	9,4
Marzahn-Hellersdorf	308	123	324	128	16	5,2	5	4,1
Lichtenberg	335	130	409	156	74	22,1	26	20,0
Reinickendorf	1 024	416	989	397	- 35	- 3,4	- 19	- 4,6
Berlin, nicht zuzuordnen	551		602					
Berlin -Gesamt-	**12 238**	**363**	**13 348**	**392**	**1 110**	**9,1**	**29**	**8,0**

Bezirk Berlin Mitte

Rauschgiftdelikte (Häufigkeitszahl)

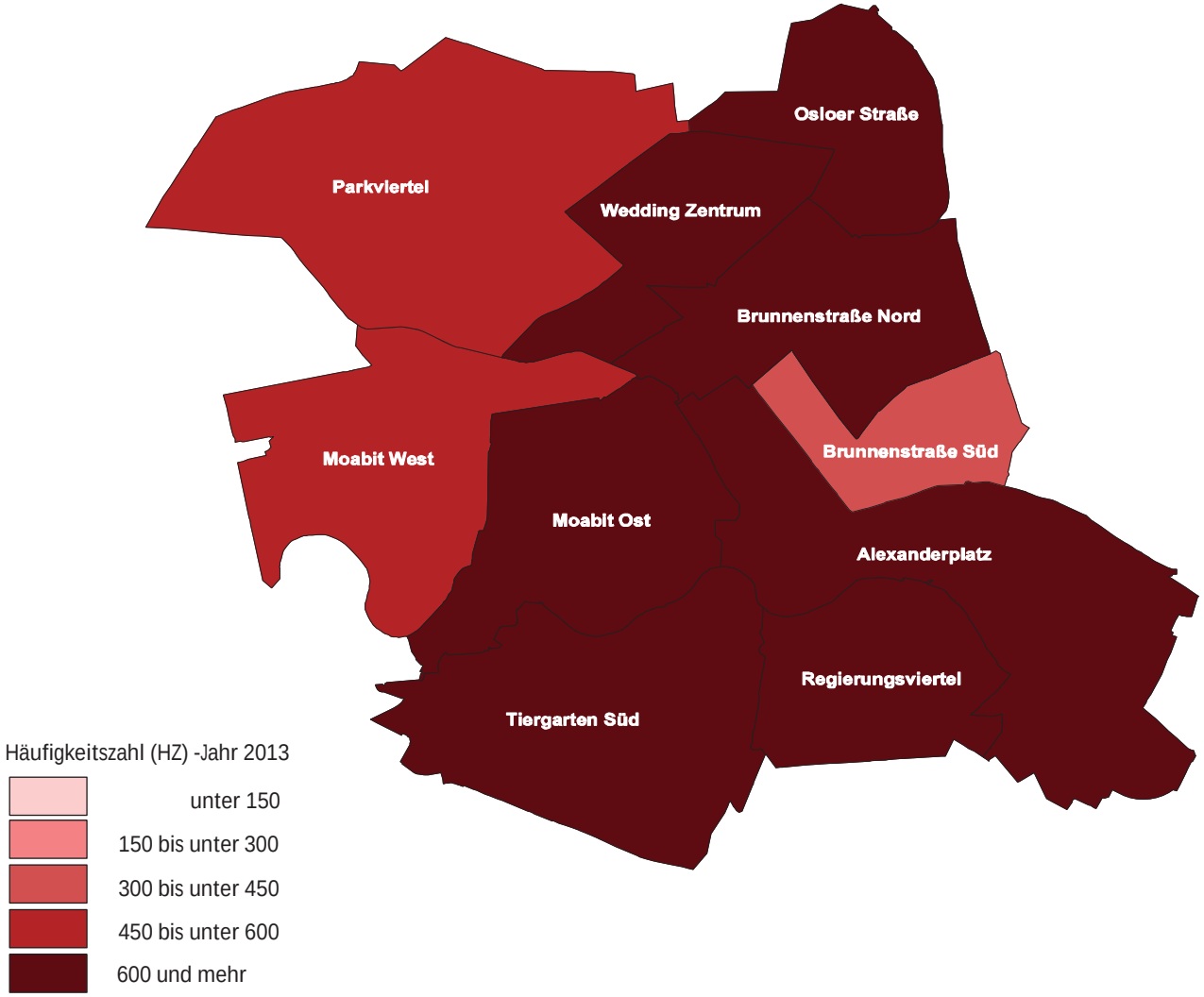

Rauschgiftdelikte (PKS-Schlüssel 730000)

Bezirksregion	Jahr 2012		Jahr 2013		Zu-/Abnahme			
	erfasste Fälle	HZ	erfasste Fälle	HZ	Fälle absolut	Fälle in %	HZ absolut	HZ in %
Tiergarten Süd	171	1 357	114	876	- 57	- 33,3	- 481	- 35,4
Regierungsviertel	98	1 069	67	721	- 31	x	- 348	(-32,6)
Alexanderplatz	435	922	590	1 226	155	35,6	304	33,0
Brunnenstraße Süd	213	833	92	346	- 121	- 56,8	- 487	- 58,5
Moabit West	259	618	209	489	- 50	- 19,3	- 129	- 20,9
Moabit Ost	416	1 194	362	1 025	- 54	- 13,0	- 169	- 14,2
Osloer Straße	246	702	366	1 011	120	48,8	309	44,0
Brunnenstraße Nord	162	459	299	834	137	84,6	375	81,7
Parkviertel	244	589	236	557	- 8	- 3,3	- 32	- 5,4
Wedding Zentrum	570	1 085	526	972	- 44	- 7,7	- 113	- 10,4
nicht zuzuordnen	35	-	3	-				

Bezirk Berlin Friedrichshain-Kreuzberg

Rauschgiftdelikte (Häufigkeitszahl)

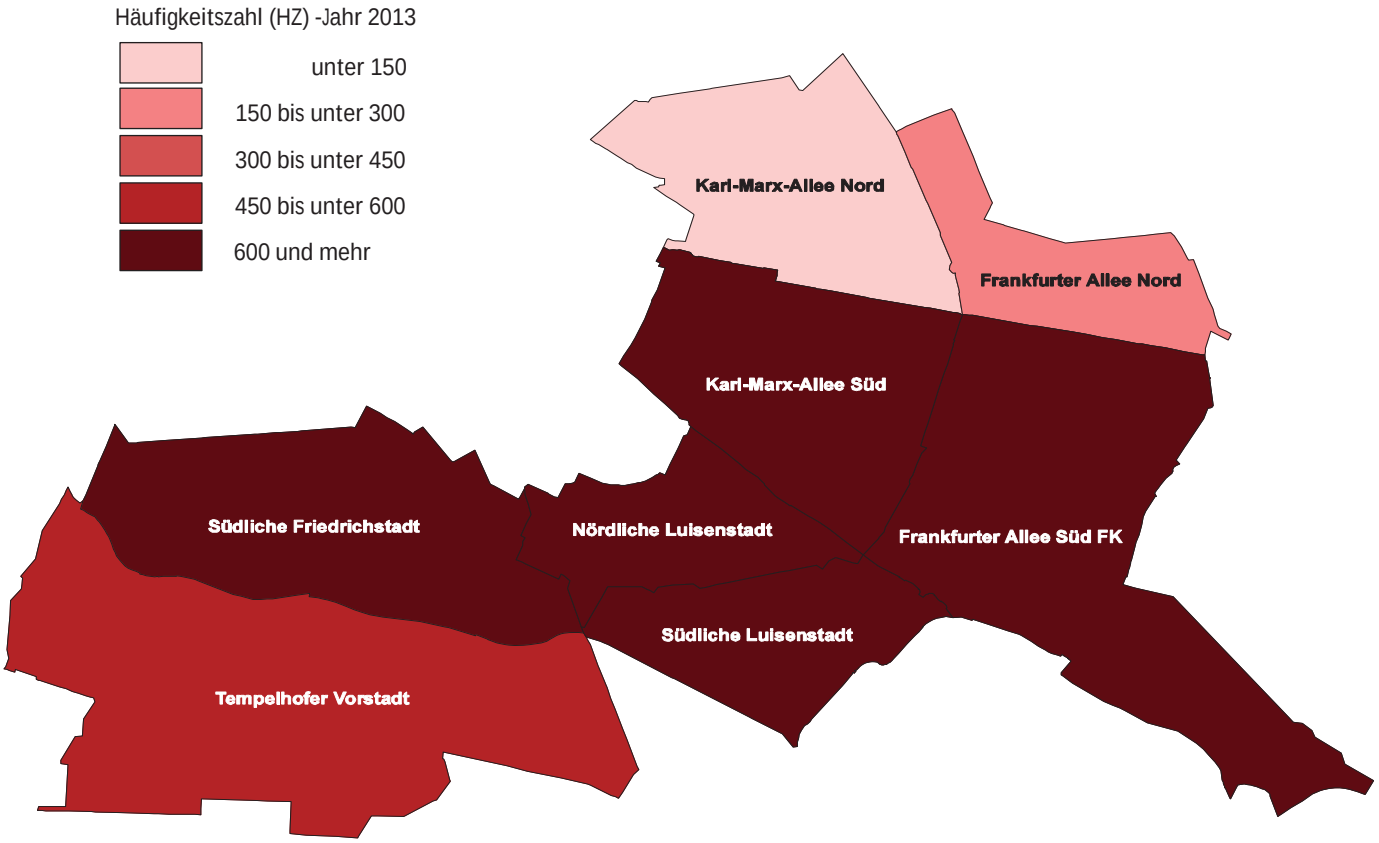

Rauschgiftdelikte (PKS-Schlüssel 730000)

Bezirksregion	Jahr 2012		Jahr 2013		Zu-/Abnahme			
	erfasste Fälle	HZ	erfasste Fälle	HZ	Fälle absolut	Fälle in %	HZ absolut	HZ in %
Südliche Friedrichstadt.....	351	901	265	671	- 86	- 24,5	- 230	- 25,5
Tempelhofer Vorstadt.....	397	652	352	568	- 45	- 11,3	- 84	- 12,9
Nördliche Luisenstadt.....	168	752	208	923	40	23,8	171	22,7
Südliche Luisenstadt.....	423	1 621	767	2 901	344	81,3	1 280	79,0
Karl-Marx-Allee Nord.....	23	103	27	120	4	x	17	(16,5)
Karl-Marx-Allee Süd.....	167	728	219	935	52	31,1	207	28,4
Frankfurter Allee Nord.....	50	184	64	232	14	x	48	(26,1)
Frankfurter Allee Süd FK.....	256	554	468	990	212	82,8	436	78,7
nicht zuzuordnen.....	18		21					

Bezirk Berlin Pankow

Rauschgiftdelikte (Häufigkeitszahl)

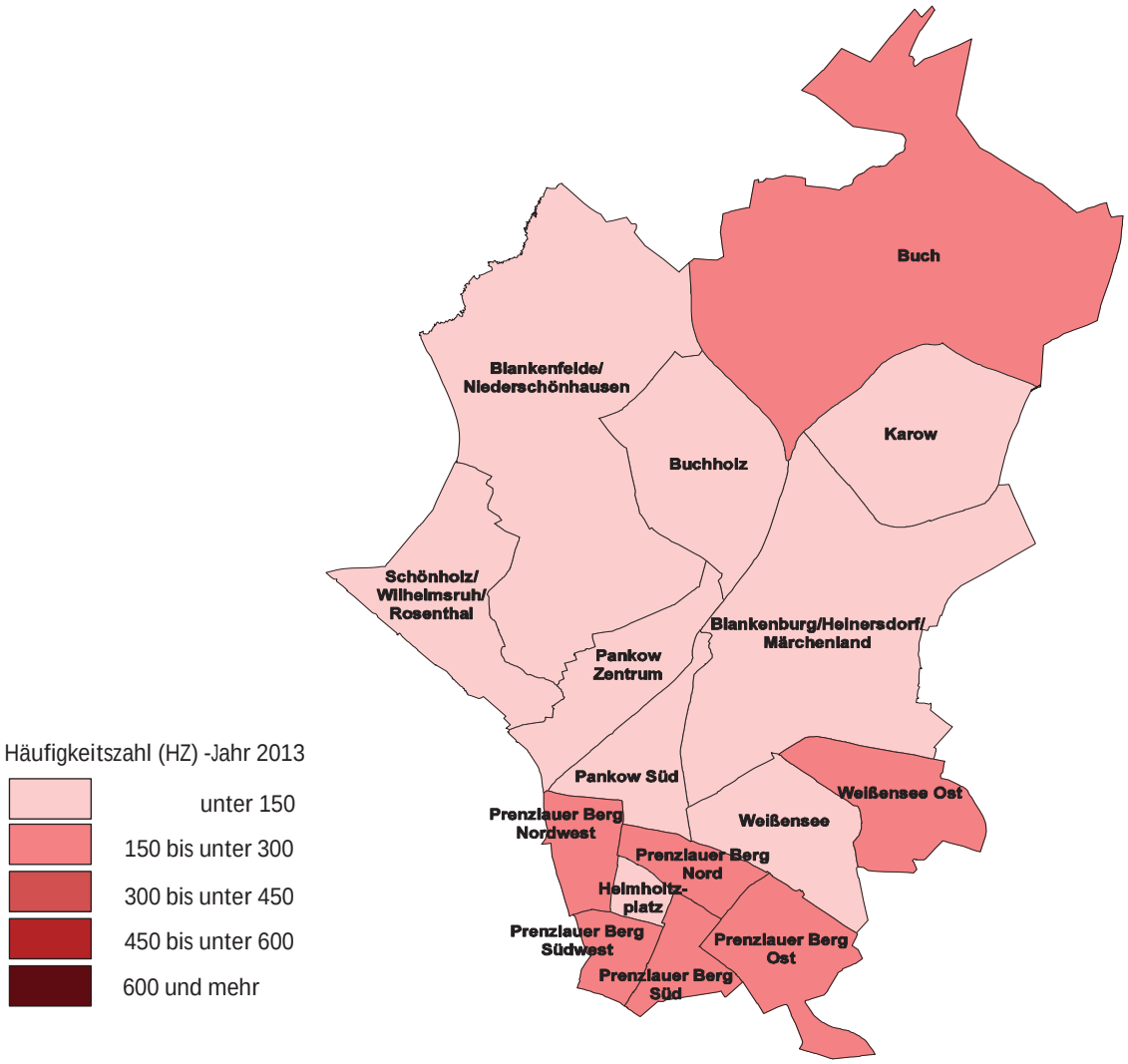

Rauschgiftdelikte (PKS-Schlüssel 730000)

Bezirksregion	Jahr 2012		Jahr 2013		Zu-/Abnahme			
	erfasste Fälle	HZ	erfasste Fälle	HZ	Fälle absolut	Fälle in %	HZ absolut	HZ in %
Buch	31	238	33	244	2	x	6	(2,5)
Blankenfelde/Niederschönhausen	11	43	15	58	4	x	15	x
Buchholz	16	95	8	47	- 8	x	- 48	x
Karow	4	21	6	32	2	x	11	x
Blankenburg/Heinersdorf	16	113	14	99	- 2	x	- 14	(- 12,4)
Pankow Süd	24	75	27	83	3	x	8	x
Schönholz/Wilhelmsruh/Rosenthal	20	117	10	58	- 10	x	- 59	(- 50,4)
Pankow Zentrum	35	108	29	87	- 6	x	- 21	(- 19,4)
Weißensee	54	164	44	131	- 10	x	- 33	(- 20,1)
Weißensee Ost	18	120	32	211	14	x	91	(75,8)
Prenzlauer Berg Nordwest	85	360	69	285	- 16	x	- 75	(- 20,8)
Prenzlauer Berg Nord	33	128	52	199	19	x	71	(55,5)
Helmholtzplatz	29	137	20	92	- 9	x	- 45	(- 32,8)
Prenzlauer Berg Ost	51	210	68	274	17	x	64	(30,5)
Prenzlauer Berg Südwest	34	140	45	181	11	x	41	(29,3)
Prenzlauer Berg Süd	53	172	47	151	- 6	x	- 21	(- 12,2)
nicht zuzuordnen	8		20					

Bezirk Berlin Charlottenburg-Wilmersdorf

Rauschgiftdelikte (Häufigkeitszahl)

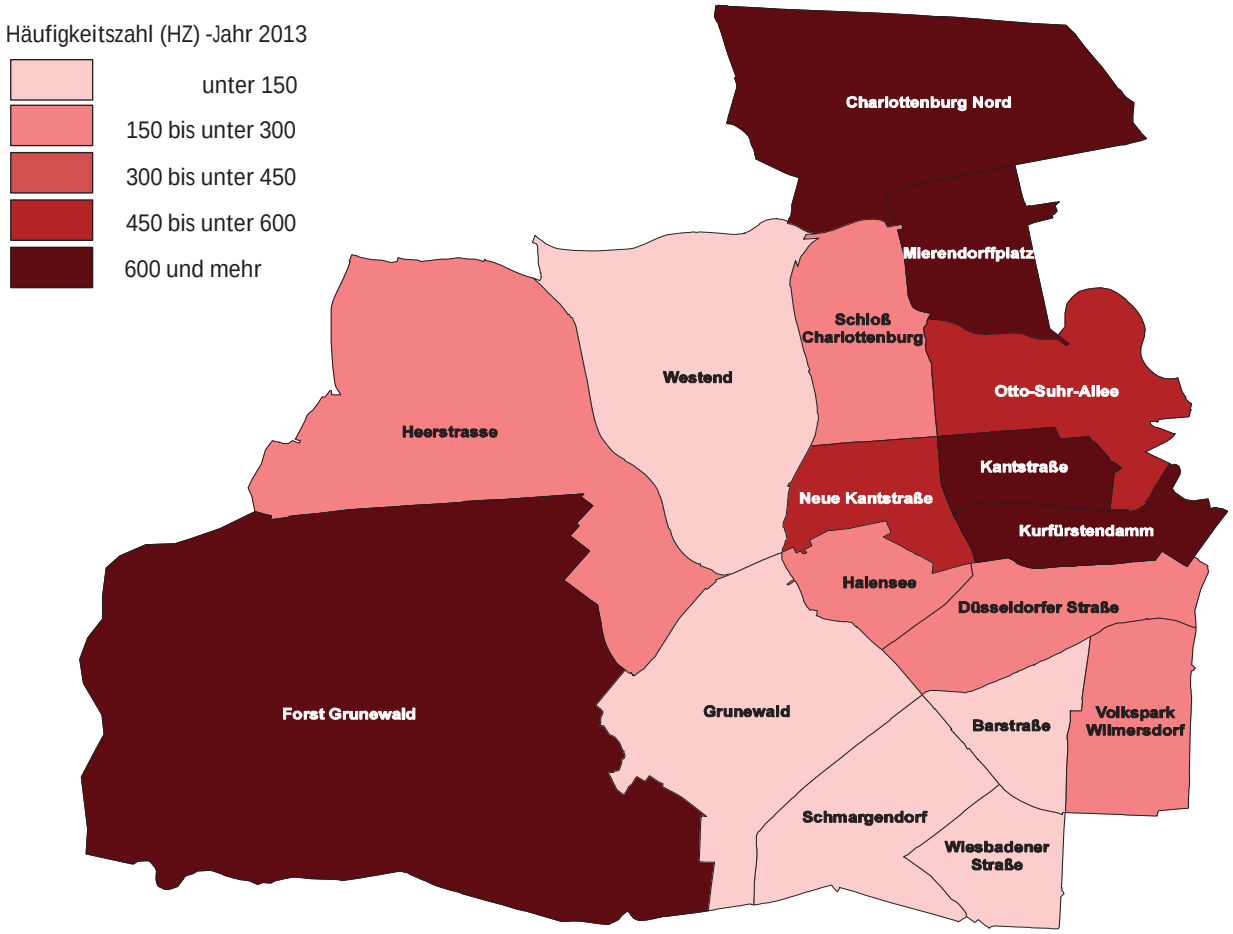

Rauschgiftdelikte (PKS-Schlüssel 730000)

Bezirksregion	Jahr 2012		Jahr 2013		Zu-/Abnahme			
	erfasste Fälle	HZ	erfasste Fälle	HZ	Fälle absolut	Fälle in %	HZ absolut	HZ in %
Charlottenburg Nord.....	159	879	156	845	- 3	- 1,9	- 34	- 3,9
Heerstraße.....	31	248	22	174	- 9	x	- 74	(- 29,8)
Westend.....	38	145	23	86	- 15	x	- 59	(- 40,7)
Schloß Charlottenburg.....	44	190	63	269	19	x	79	(41,6)
Mierendorffplatz.....	111	780	96	658	- 15	- 13,5	- 122	- 15,6
Otto-Suhr-Allee.....	112	440	141	547	29	25,9	107	24,3
Neue Kantstraße.....	80	349	135	582	55	x	233	(66,8)
Kantstraße.....	118	577	165	796	47	39,8	219	38,0
Kurfürstendamm.....	178	1 222	197	1 351	19	10,7	129	10,6
Halensee.....	26	183	30	208	4	x	25	(13,7)
Grunewald.....	5	28	13	71	8	x	43	x
Schmargendorf.....	10	72	8	58	- 2	x	- 14	x
Wiesbadener Straße.....	9	50	2	11	- 7	x	- 39	x
Düsseldorfer Straße.....	54	184	52	175	- 2	x	- 9	(- 4,9)
Barstraße.....	14	104	20	147	6	x	43	(41,3)
Volkspark Wilmersdorf.....	63	195	50	152	- 13	x	- 43	(- 22,1)
Forst Grunewald.....			2		2	x		
nicht zuzuordnen.....	12		5					

Bezirk Berlin Spandau

Rauschgiftdelikte (Häufigkeitszahl)

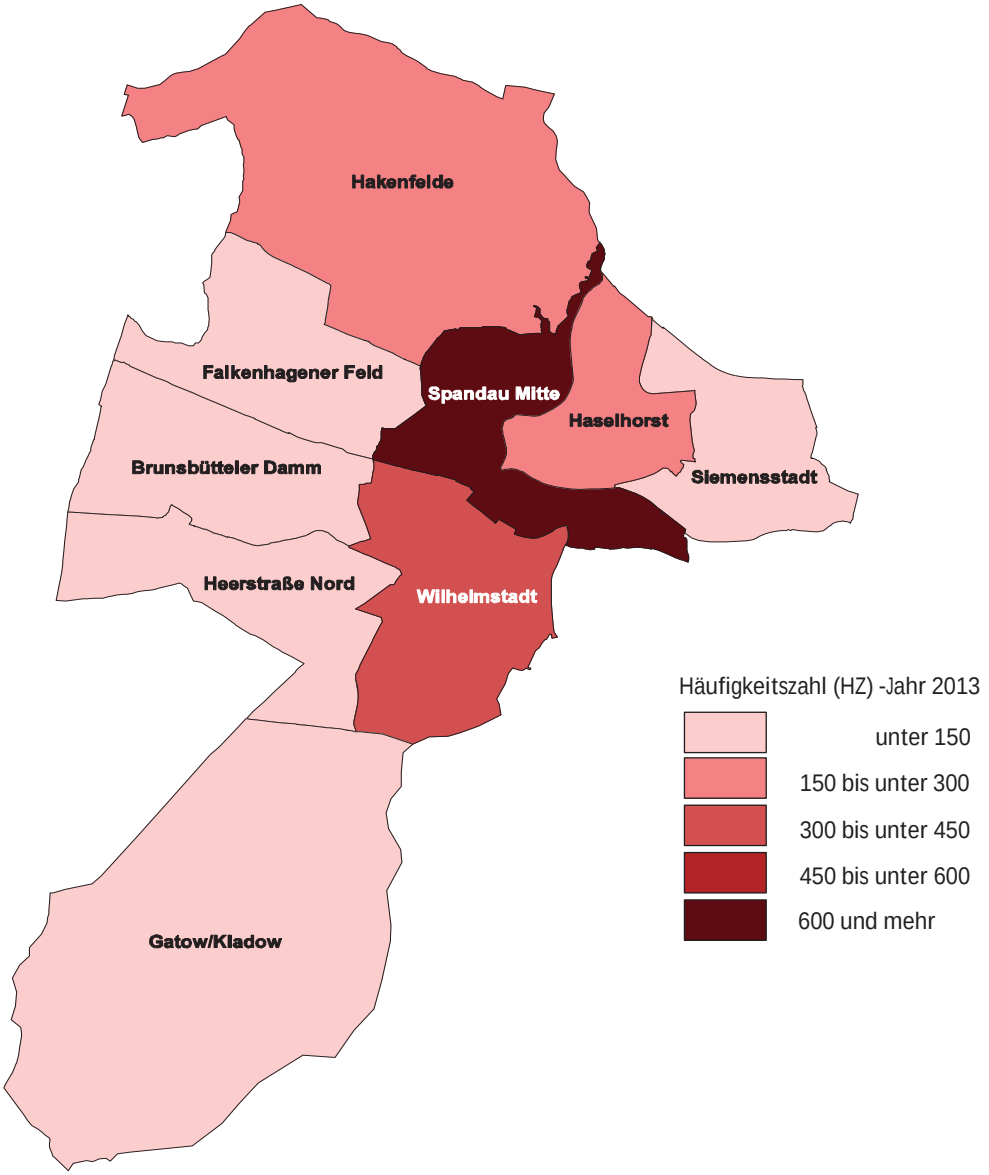

Rauschgiftdelikte (PKS-Schlüssel 730000)

Bezirksregion	Jahr 2012		Jahr 2013		Zu-/Abnahme			
	erfasste Fälle	HZ	erfasste Fälle	HZ	Fälle absolut	Fälle in %	HZ absolut	HZ in %
Hakenfelde.....	28	124	40	176	12	x	52	(41,9)
Falkenhagener Feld.....	54	138	46	117	- 8	x	- 21	(- 15,2)
Spandau Mitte.....	206	627	223	662	17	8,3	35	5,6
Brunsbütteler Damm.....	11	48	21	91	10	x	43	x
Heerstraße Nord.....	29	109	34	127	5	x	18	(16,5)
Wilhelmstadt.....	89	263	120	349	31	x	86	(32,7)
Haselhorst.....	39	283	25	173	- 14	x	- 110	(- 38,9)
Siemensstadt.....	25	215	12	100	- 13	x	- 115	(- 53,5)
Gatow/Kladow.....		-	4	22	4	x	22	x
nicht zuzuordnen.....			3					

Bezirk Berlin Steglitz-Zehlendorf

Rauschgiftdelikte (Häufigkeitszahl)

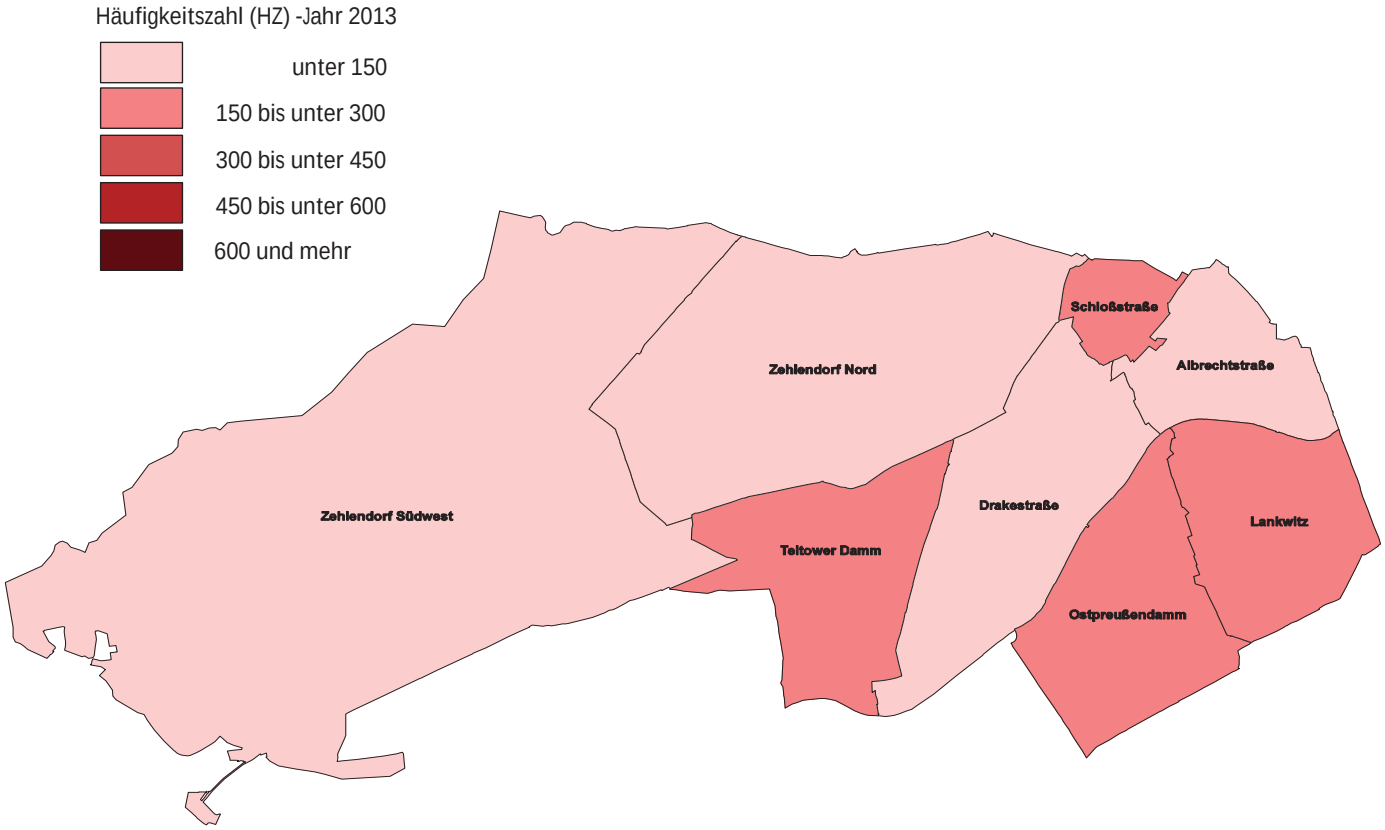

Rauschgiftdelikte (PKS-Schlüssel 730000)

Bezirksregion	Jahr 2012		Jahr 2013		Zu-/Abnahme			
	erfasste Fälle	HZ	erfasste Fälle	HZ	Fälle		HZ	
					absolut	in %	absolut	in %
Schloßstraße.....	50	234	40	185	- 10	x	- 49	(- 20,9)
Albrechtstraße.....	44	86	59	114	15	x	28	x
Lankwitz.....	55	133	88	211	33	x	78	(58,6)
Ostpreußendamm.....	29	84	55	157	26	x	73	x
Teltower Damm.....	50	153	51	156	1	x	3	(2,0)
Drakestraße.....	21	46	49	105	28	x	59	x
Zehlendorf Südwest.....	17	67	33	129	16	x	62	x
Zehlendorf Nord.....	29	70	46	111	17	x	41	x
nicht zuzuordnen.....	3		2					

Bezirk Berlin Tempelhof-Schöneberg

Rauschgiftdelikte (Häufigkeitszahl)

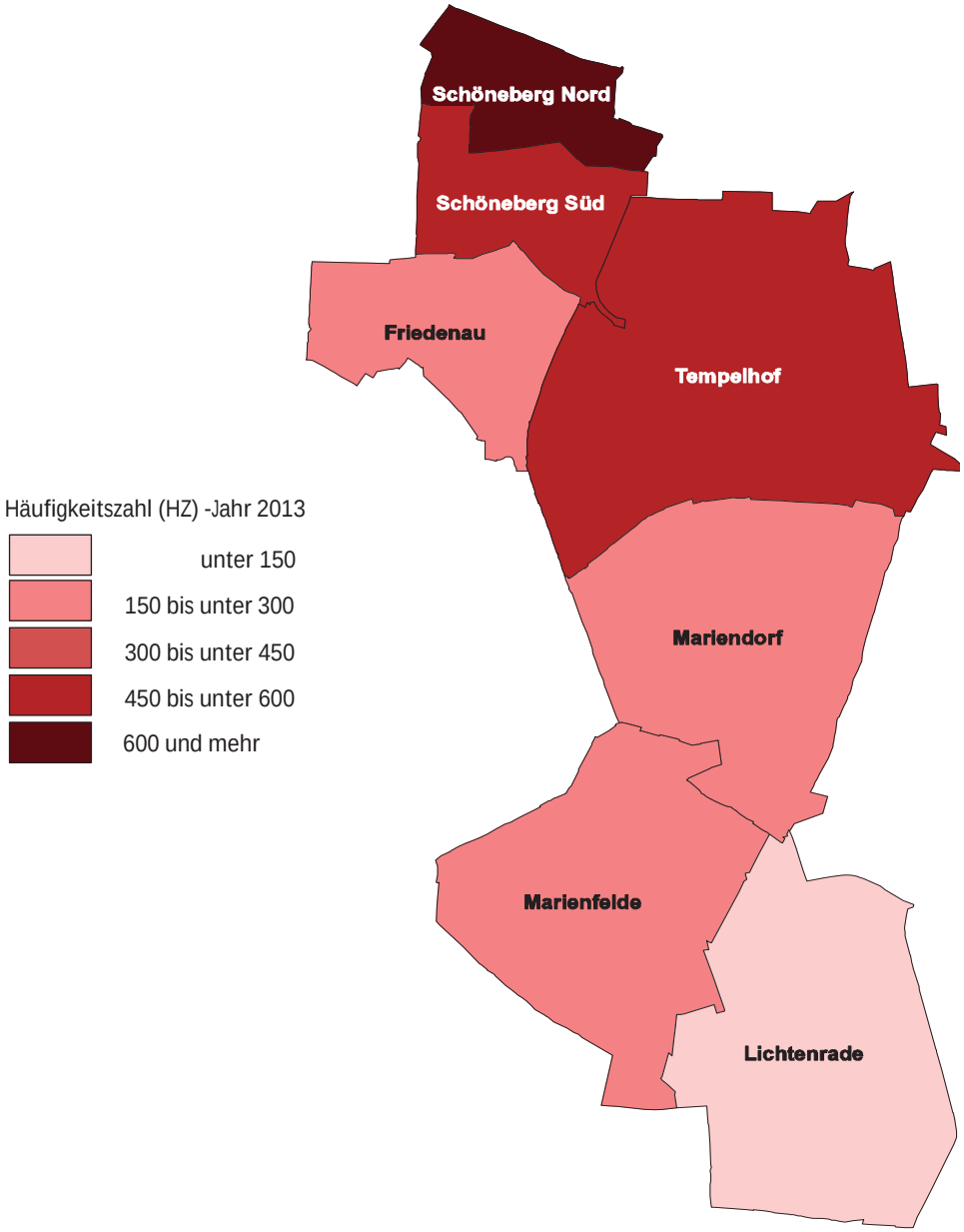

Rauschgiftdelikte (PKS-Schlüssel 730000)

Bezirksregion	Jahr 2012		Jahr 2013		Zu-/Abnahme			
	erfasste Fälle	HZ	erfasste Fälle	HZ	Fälle absolut	Fälle in %	HZ absolut	HZ in %
Schöneberg Nord.....	214	454	307	654	93	43,5	200	44,1
Schöneberg Süd.....	239	503	218	457	- 21	- 8,8	- 46	- 9,1
Friedenau.....	70	159	75	169	5	x	10	(6,3)
Tempelhof.....	291	494	300	500	9	3,1	6	1,2
Mariendorf.....	84	169	102	204	18	x	35	(20,7)
Marienfelde.....	54	177	50	164	- 4	x	- 13	(- 7,3)
Lichtenrade.....	87	176	64	129	- 23	x	- 47	(- 26,7)
nicht zuzuordnen.....	27		6					

Bezirk Berlin Neukölln

Rauschgiftdelikte (Häufigkeitszahl)

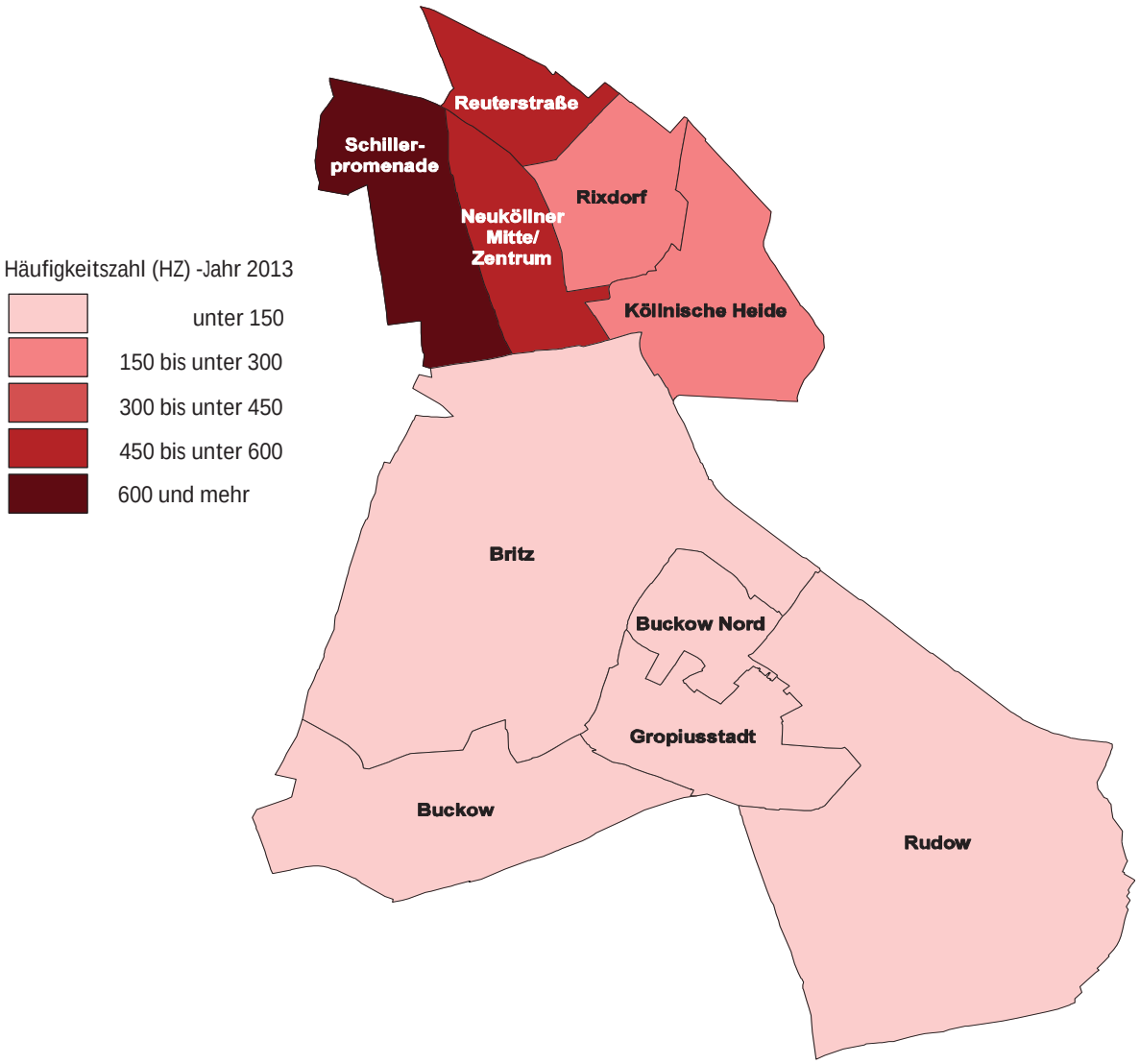

Rauschgiftdelikte (PKS-Schlüssel 730000)

Bezirksregion	Jahr 2012		Jahr 2013		Zu-/Abnahme			
	erfasste Fälle	HZ	erfasste Fälle	HZ	Fälle absolut	Fälle in %	HZ absolut	HZ in %
Schillerpromenade	913	2 952	929	2 943	16	1,8	- 9	- 0,3
Neuköllner Mitte/Zentrum	154	417	200	530	46	29,9	113	27,1
Reuterstraße	226	582	232	584	6	2,7	2	0,3
Rixdorf	103	265	110	278	7	6,8	13	4,9
Köllnische Heide	39	265	29	193	- 10	x	- 72	(- 27,2)
Britz	65	160	53	129	- 12	x	- 31	(- 19,4)
Buckow	14	51	23	83	9	x	32	x
Gropiusstadt	32	89	28	77	- 4	x	- 12	x
Buckow Nord	6	65	5	53	- 1	x	- 12	x
Rudow	23	55	16	38	- 7	x	- 17	x
nicht zuzuordnen	3		10					

Bezirk Berlin Treptow-Köpenick

Rauschgiftdelikte (Häufigkeitszahl)

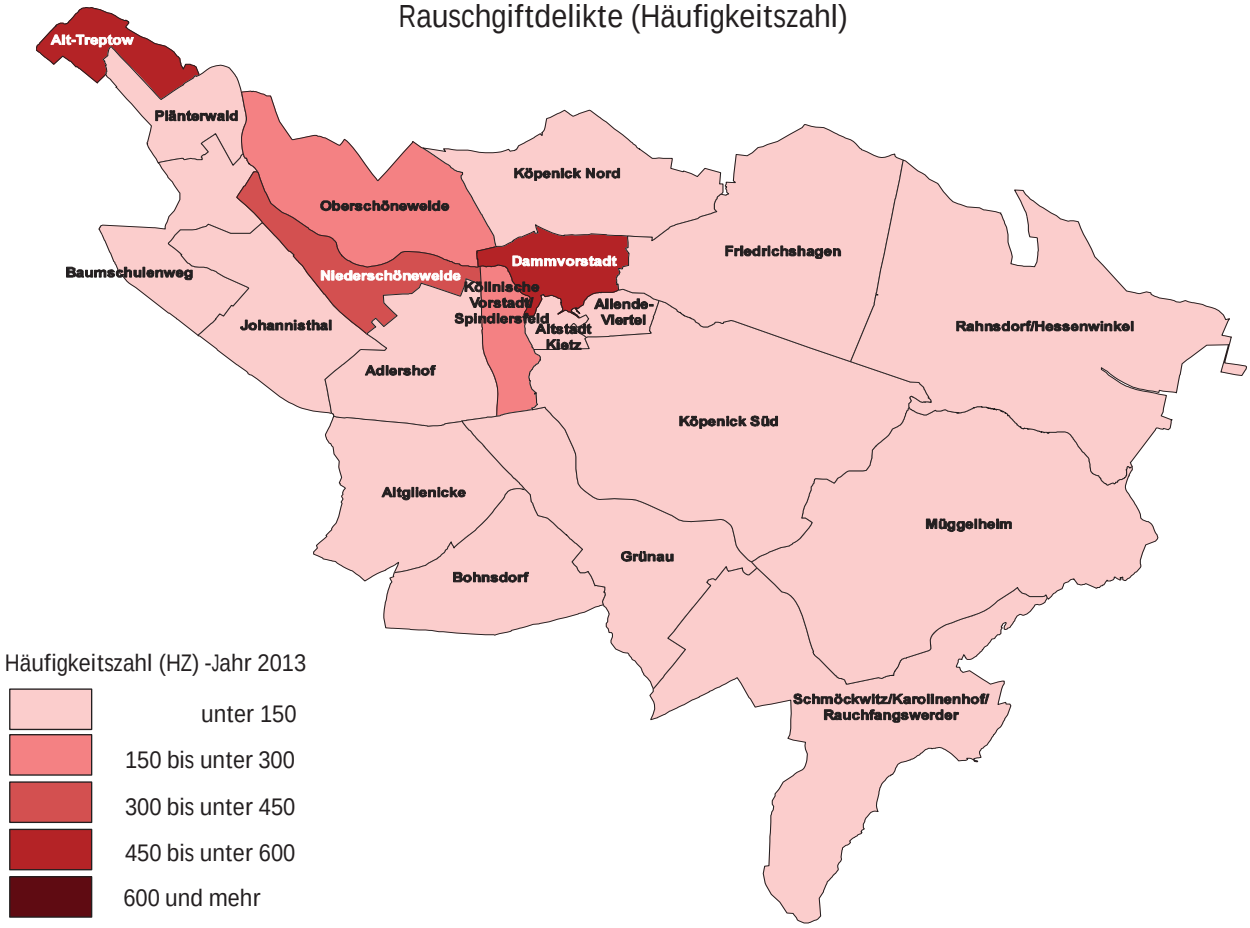

Rauschgiftdelikte (PKS-Schlüssel 730000)

Bezirksregion	Jahr 2012		Jahr 2013		Zu-/Abnahme			
	erfasste Fälle	HZ	erfasste Fälle	HZ	Fälle absolut	Fälle in %	HZ absolut	HZ in %
Alt-Treptow	43	394	65	586	22	x	192	(48,7)
Plänterwald	4	37	6	55	2	x	18	x
Baumschulenweg	37	215	24	138	- 13	x	- 77	(- 35,8)
Johannisthal	11	60	15	81	4	x	21	x
Oberschöneweide	31	162	41	208	10	x	46	(28,4)
Niederschöneweide	40	383	32	301	- 8	x	- 82	(- 21,4)
Adlershof	20	130	13	83	- 7	x	- 47	(- 36,2)
Kölln. Vorstadt/Spindlersf.	17	173	20	200	3	x	27	(15,6)
Altglienicke	14	55	23	89	9	x	34	x
Bohnsdorf	13	109	14	116	1	x	7	(6,4)
Grünau	3	56	7	125	4	x	69	x
Schmöckwitz/Karolinenhof		-		-		x		x
Köpenick Süd	7	45	7	45		x		x
Allende-Viertel	2	33	2	33		x		x
Altstadt Kietz	10	146	5	72	- 5	x	- 74	(- 50,7)
Müggelheim	1	15	1	15		x		x
Friedrichshagen	6	34	2	11	- 4	x	- 23	x
Rahnsdorf/Hessenwinkel	2	22	2	22		x		x
Dammvorstadt	35	371	51	536	16	x	165	(44,5)
Köpenick Nord	6	49	1	8	- 5	x	- 41	x
nicht zuzuordnen	7		11					

Bezirk Berlin Marzahn-Hellersdorf

Rauschgiftdelikte (Häufigkeitszahl)

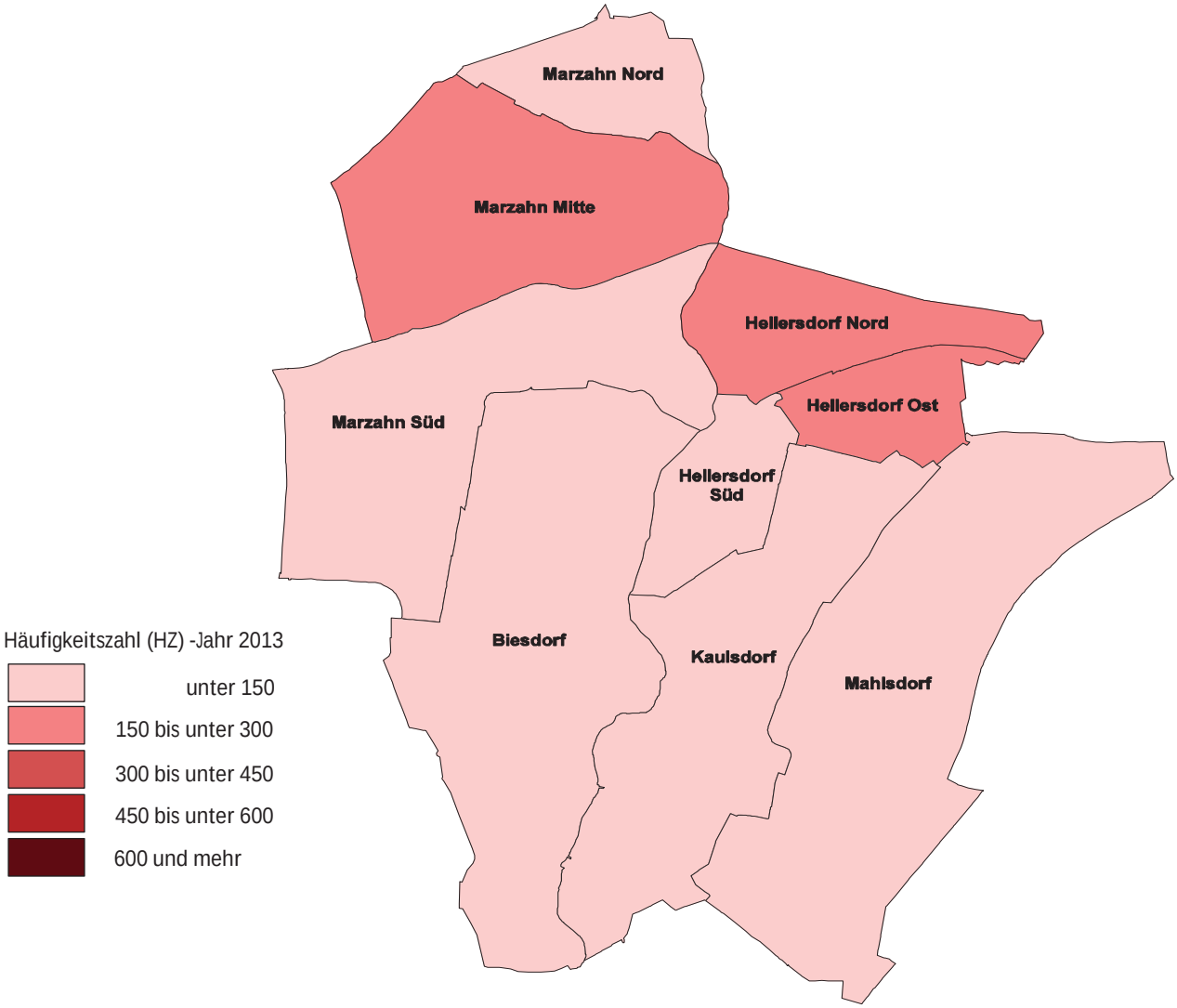

Rauschgiftdelikte (PKS-Schlüssel 730000)

Bezirksregion	Jahr 2012		Jahr 2013		Zu-/Abnahme			
	erfasste Fälle	HZ	erfasste Fälle	HZ	Fälle		HZ	
					absolut	in %	absolut	in %
Marzahn Nord	49	216	33	144	- 16	x	- 72	(- 33,3)
Marzahn Mitte	77	170	78	171	1	x	1	(0,6)
Marzahn Süd	19	53	23	63	4	x	10	x
Hellersdorf Nord	70	213	83	249	13	x	36	(16,9)
Hellersdorf Ost	21	114	32	170	11	x	56	(49,1)
Hellersdorf Süd	15	62	33	135	18	x	73	x
Biesdorf	21	84	18	71	- 3	x	- 13	x
Kaulsdorf	8	43	7	38	- 1	x	- 5	x
Mahlsdorf	23	85	15	55	- 8	x	- 30	x
nicht zuzuordnen	5		2					

Bezirk Berlin Lichtenberg

Rauschgiftdelikte (Häufigkeitszahl)

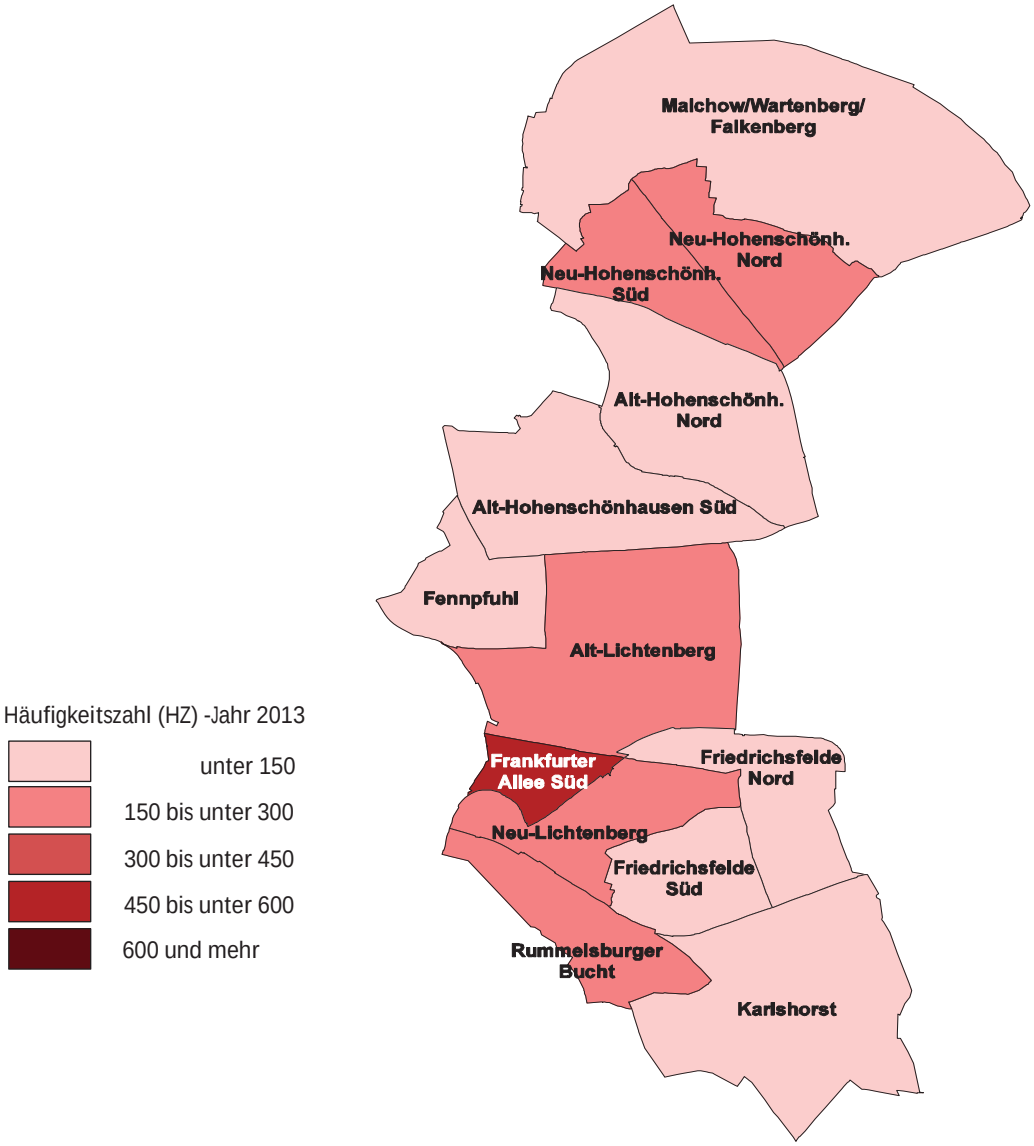

Rauschgiftdelikte (PKS-Schlüssel 730000)

Bezirksregion	Jahr 2012		Jahr 2013		Zu-/Abnahme			
	erfasste Fälle	HZ	erfasste Fälle	HZ	Fälle absolut	Fälle in %	HZ absolut	HZ in %
Malchow/Warten-/Falkenberg.....	5	119	5	118		x	- 1	(- 0,8)
Neu-Hohenschönhausen Nord.....	40	146	67	242	27	x	96	(65,8)
Neu-Hohenschönhausen Süd.....	21	81	40	155	19	x	74	x
Alt-Hohenschönhausen Nord.....	12	89	14	104	2	x	15	x
Alt-Hohenschönhausen Süd.....	13	44	34	115	21	x	71	x
Fennpfuhl.....	22	69	25	78	3	x	9	x
Alt-Lichtenberg.....	35	146	56	225	21	x	79	(54,1)
Frankfurter Allee Süd.....	52	538	53	529	1	x	- 9	(- 1,7)
Neu-Lichtenberg.....	62	211	65	216	3	x	5	(2,4)
Friedrichsfelde Nord.....	24	180	17	126	- 7	x	- 54	(- 30,0)
Friedrichsfelde Süd.....	17	71	14	57	- 3	x	- 14	x
Rummelsburger Bucht.....	2	61	8	241	6	x	180	x
Karlshorst.....	24	106	5	21	- 19	x	- 85	(- 80,2)
nicht zuzuordnen.....	6		6					

Bezirk Berlin Reinickendorf

Rauschgiftdelikte (Häufigkeitszahl)

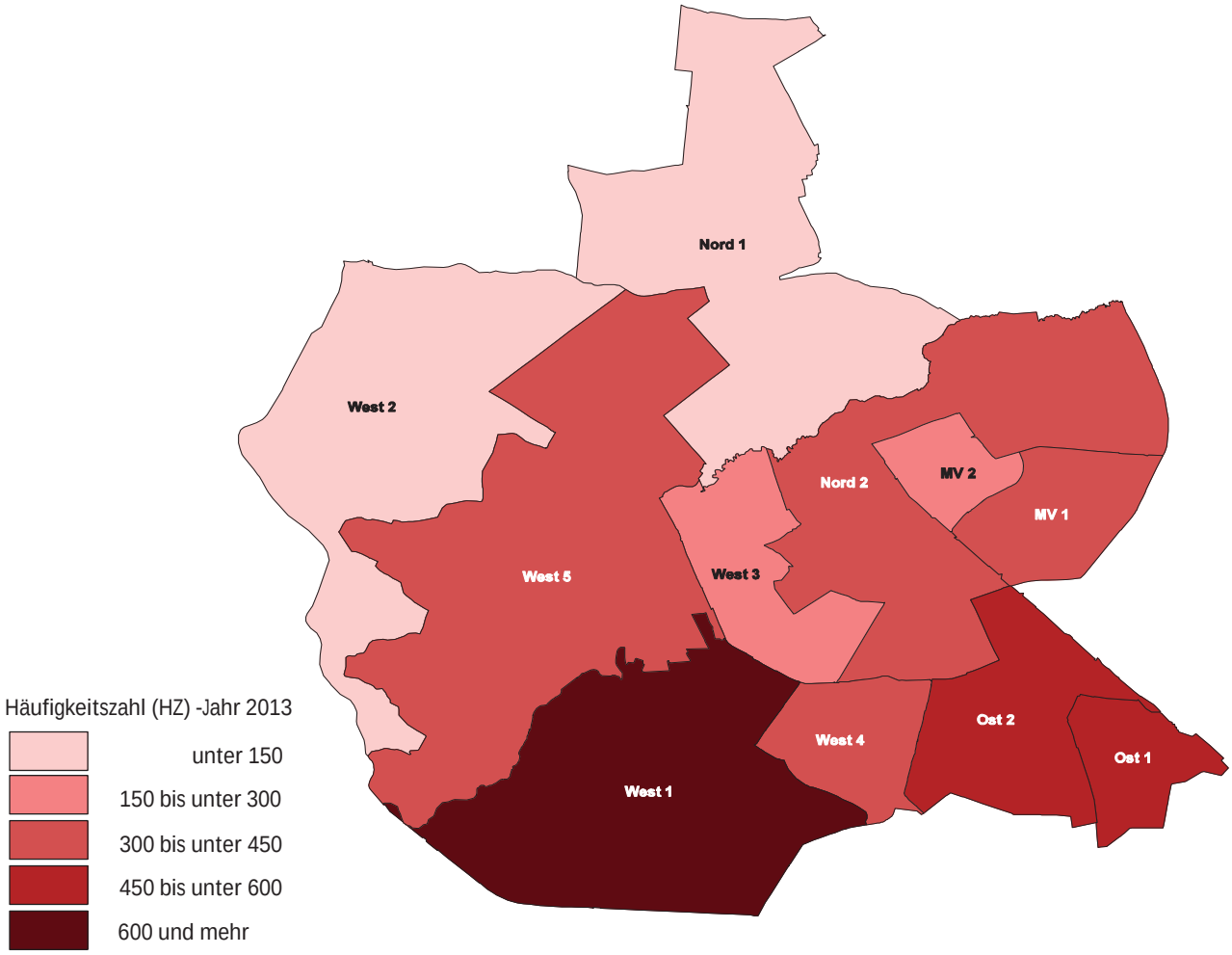

Rauschgiftdelikte (PKS-Schlüssel 730000)

Bezirksregion	Jahr 2012		Jahr 2013		Zu-/Abnahme			
	erfasste Fälle	HZ	erfasste Fälle	HZ	Fälle		HZ	
					absolut	in %	absolut	in %
Ost 1	137	534	132	508	- 5	- 3,6	- 26	- 4,9
Ost 2	149	584	152	588	3	2,0	4	0,7
West 1	312	2 145	228	1 576	- 84	- 26,9	- 569	- 26,5
West 4	86	344	100	393	14	x	49	(14,2)
West 5	34	333	41	398	7	x	65	(19,5)
West 2	24	102	27	114	3	x	12	(11,8)
Nord 1	40	122	19	58	- 21	x	- 64	(- 52,5)
Nord 2	103	353	97	326	- 6	- 5,8	- 27	- 7,6
MV 1	76	215	139	382	63	x	167	(77,7)
MV 2	18	220	14	165	- 4	x	- 55	(- 25,0)
West 3	40	250	33	206	- 7	x	- 44	(- 17,6)
nicht zuzuordnen	5		7					